SEMESTER 2

Katalog: 1304053.32

MASTER FILE DESA
PROVINSI JAWA BARAT
2022

https://jabar.bps.go.id

BADAN PUSAT STATISTIK
PROVINSI JAWA BARAT

SEMESTER 2

MASTER FILE DESA
PROVINSI JAWA BARAT

2022

https://ppss.go.id

MASTER FILE DESA
PROVINSI JAWA BARAT 2022

No. Publikasi : 32000.2238
Katalog : 1304053.32
Ukuran Buku : 15 x 21 cm
Jumlah Halaman : viii + 762 Halaman

Naskah :
Badan Pusat Statistik Provinsi Jawa Barat

Penyunting :
Badan Pusat Statistik Provinsi Jawa Barat

Gambar Sampul :
Badan Pusat Statistik Provinsi Jawa Barat

Diterbitkan oleh :
©Badan Pusat Statistik Provinsi Jawa Barat

Dicetak oleh:
Badan Pusat Statistik Provinsi Jawa Barat

Dilarang mengumumkan, mendistribusikan, mengomunikasikan, dan/atau menggandakan sebagian atau seluruh buku ini untuk tujuan komersial tanpa izin tertulis dari Badan Pusat Statistik.

https://jabar.bps.go.id

MASTER FILE DESA
PROVINSI JAWA BARAT 2022
(Data Tahun 2021 Semester 2)

TIM PENYUSUN

Pengarah	: Marsudijono S.Si., MM
Koordinator Teknis	: Yudi Purbosari, S.S.T., M.T.
Naskah	: Asnafiya Asrof, SST, M.Stat
Gambar Sampul	: Dimas Tresna Suhartono, S.ST
Penyunting	: Nani Komalasari, SE

https://jabar.bps.go.id

https://jabar.bps.go.id

KATA PENGANTAR

Publikasi Master File Desa Provinsi Jawa Barat 2022 merupakan publikasi rutin yang diterbitkan oleh Badan Pusat Statistik (BPS) Provinsi Jawa Barat setiap Semester. Penerbitan publikasi sesuai dengan Peraturan Kepala Badan Pusat Statistik Republik Indonesia Nomor 3 Tahun 2019 tentang Kode dan Nama Wilayah Kerja Statistik yang berupaya menginventarisasi perkembangan kondisi wilayah, baik karena pemekaran, pemecahan, atau pun penggabungan wilayah administrasi.

Master File Desa merupakan salah satu bagian dari wilayah kerja statistik yang digunakan sebagai acuan nama desa pada kegiatan sensus dan survei BPS. Kode Master File Desa merupakan identitas yang meliputi :

- Dua digit pertama merupakan nomor kode provinsi;
- Digit ketiga dan keempat merupakan nomor kode kabupaten/kota;
- Digit kelima sampai ketujuh merupakan nomor kode kecamatan;
- Digit kedelapan sampai kesepuluh menunjukkan nomor kode desa/ kelurahan.

Semoga publikasi ini bermanfaat bagi pengguna data. Akhir kata, kami mengharapkan kritik dan saran yang membangun untuk menjadikan publikasi ini semakin baik ke depannya.

Bandung, Agustus 2022
Kepala BPS Provinsi Jawa Barat

Marsudijono

https://jabar.bps.go.id

https://jabar.bps.go.id

DAFTAR ISI

Uraian Halaman

Kata Pengantar v
Daftar Isi vii
Ulasan Perubahan Master File Desa Provinsi Jawa Barat 2022 1
Peta Provinsi Jawa Barat 2
Tabel Jumlah Kecamatan dan Desa/Kelurahan Menurut Kabupaten/
Kota di Provinsi Jawa Barat..... 5
Kabupaten Bogor (3201) 7
Kabupaten Sukabumi (3202) 53
Kabupaten Cianjur (3203) 107
Kabupaten Bandung (3204) 145
Kabupaten Garut (3205) 183
Kabupaten Tasikmalaya (3206) 233
Kabupaten Ciamis (3207)..... 279
Kabupaten Kuningan (3208) 311
Kabupaten Cirebon (3209) 349
Kabupaten Majalengka (3210) 395
Kabupaten Sumedang (3211) 425
Kabupaten Indramayu (3212) 456
Kabupaten Subang (3213) 493
Kabupaten Purwakarta (3214) 529
Kabupaten Karawang (3215)..... 551
Kabupaten Bekasi (3216) 587
Kabupaten Bandung Barat (3217) 615
Kabupaten Pangandaran (3218) 635
Kota Bogor (3271) 649
Kota Sukabumi (3272) 659
Kota Bandung (3273) 667
Kota Cirebon (3274) 697
Kota Bekasi (3275)..... 707
Kota Depok (3276) 719
Kota Cimahi (3277) 735
Kota Tasikmalaya (3278) 741
Kota Banjar (3279) 755

https://jabar.bps.go.id

https://jabar.bps.go.id

ULASAN PERUBAHAN MASTER FILE DESA PROVINSI JAWA BARAT 2022

Wilayah Kerja Statistik adalah wilayah kerja untuk kegiatan sensus dan survei yang diselenggarakan oleh Badan Pusat Statistik. Informasi Wilayah Kerja Statistik yang dipergunakan berisi Kode dan Nama Wilayah Kerja Statistik yang meliputi kode dan Nama provinsi, kode dan nama Kabupaten/Kota, kode dan nama Kecamatan dan kode dan nama desa/kelurahan.

Master File Desa merupakan salah satu bagian dari Wilayah Kerja Statistik yang digunakan sebagai acuan nama-nama desa pada kegiatan sensus dan survei. Berdasarkan hasil pemutakhiran Master File Desa yang diselenggarakan pada semester 2 tahun 2021, terdapat 27 Kabupaten/Kota, 627 Kecamatan dan 5.957 Desa/Kelurahan di Jawa Barat terdiri dari 2.672 urban dan 3.285 rural. Tidak terjadi perubahan berdasarkan wilayah kerja statistik dari hasil pemutakhiran Master File Desa yang dilaksanakan pada semester 2 tahun 2020 dan semester 1 tahun 2021.

Dalam Publikasi Master File Desa tahun ini, disajikan juga perbandingan Daftar Kecamatan dan Kelurahan/Desa dari Kemendagri dan Daftar Kecamatan dan Kelurahan/Desa dari Hasil MFD 2021 Semester 2.

https://jabar.bps.go.id

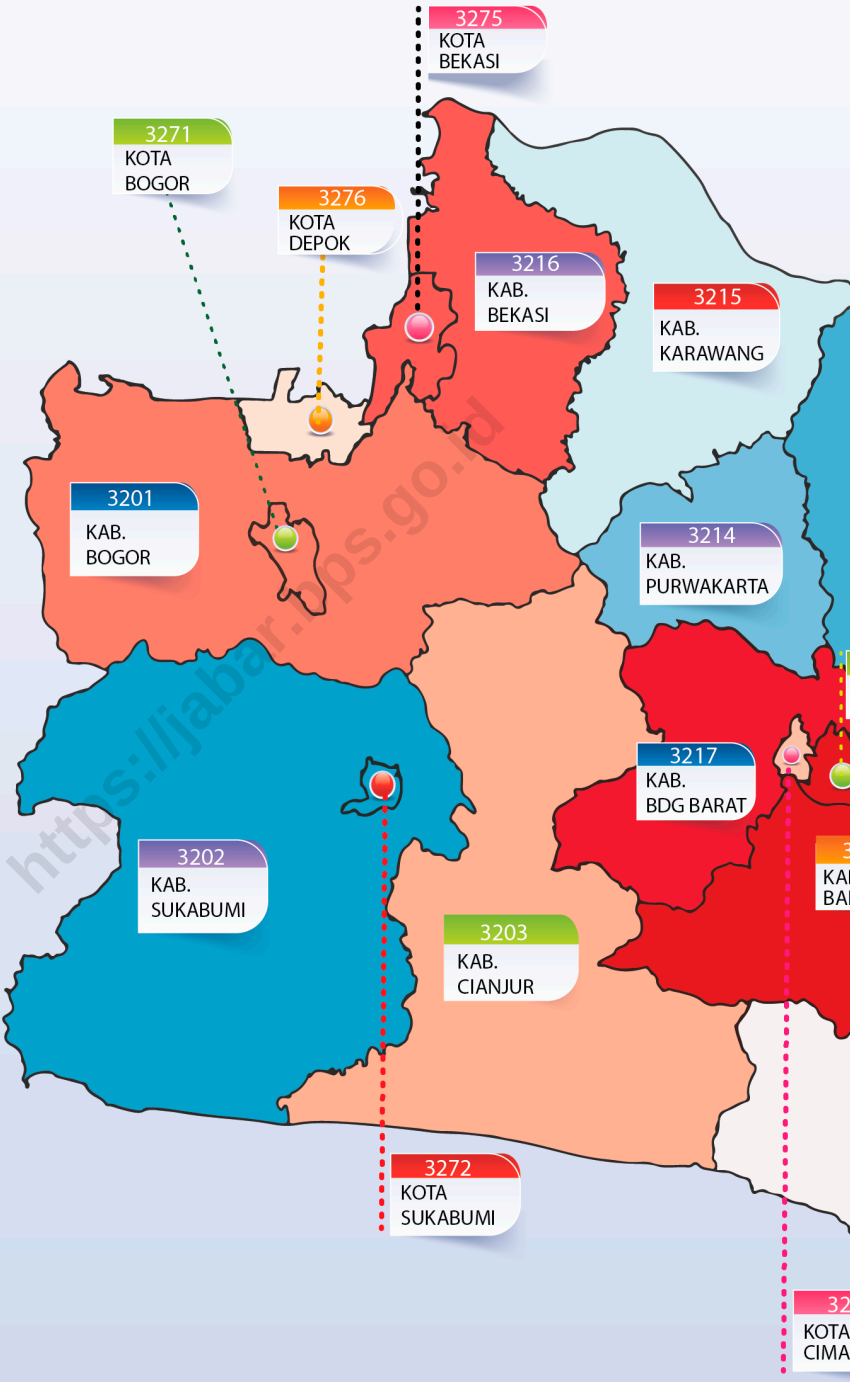

https://jabar.bps.go.id

PETA PROVINSI JAWA BARAT

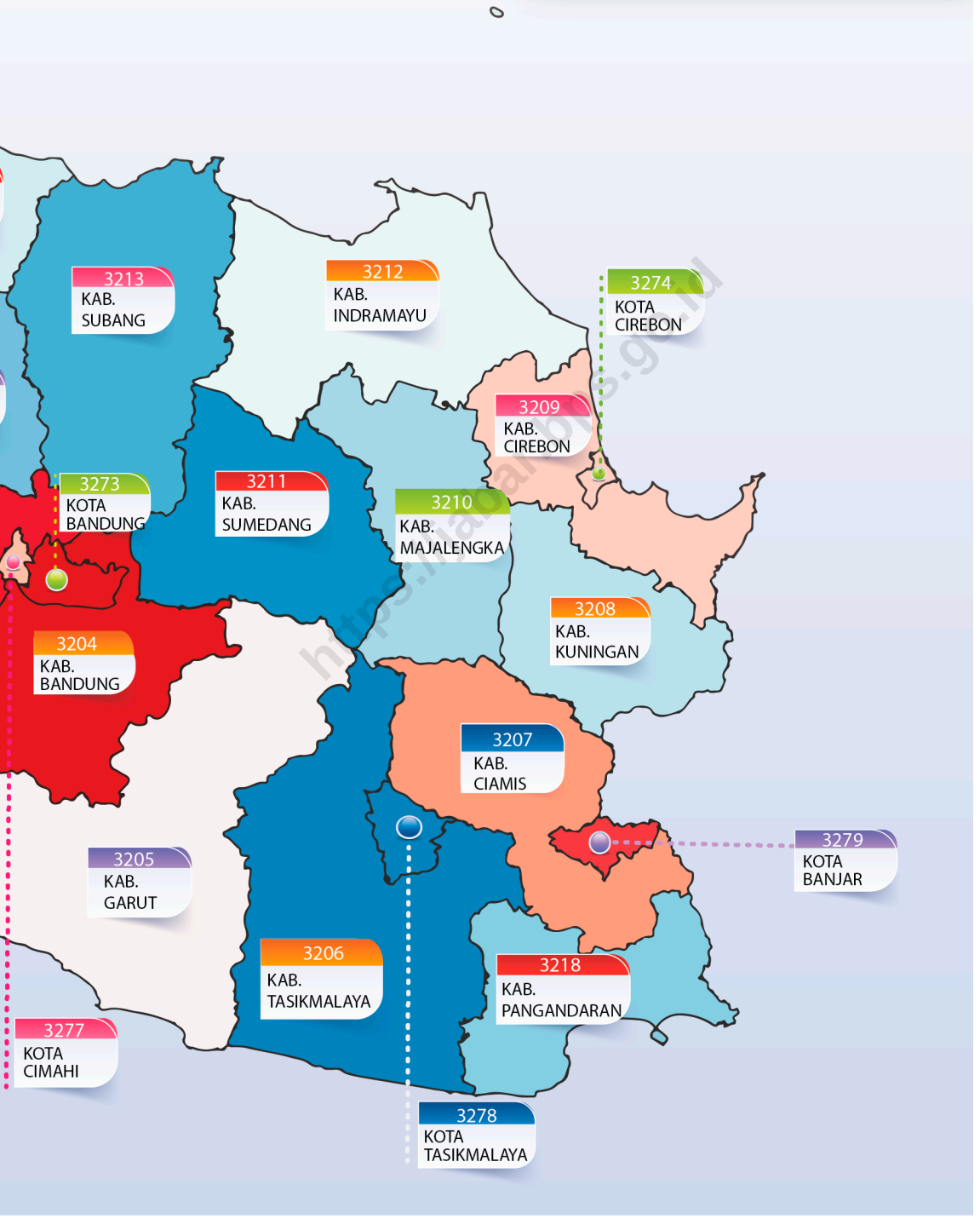

https://jabar.bps.go.id

TABEL JUMLAH KECAMATAN DAN KELURAHAN/ DESA MENURUT KABUPATEN/KOTA DI PROVINSI JAWA BARAT

Kabupaten/Kota	2021 Semester 1		2021 Semester 2		
	Jumlah Kec.	Jumlah Desa/Kel.	Jumlah Kec.	Jumlah Desa/Kel.	
				Urban	Rural
[01] BOGOR	40	435	40	292	143
[02] SUKABUMI	47	386	47	120	266
[03] CIANJUR	32	360	32	73	287
[04] BANDUNG	31	280	31	211	69
[05] GARUT	42	442	42	162	280
[06] TASIKMALAYA	39	351	39	76	275
[07] CIAMIS	27	265	27	65	200
[08] KUNINGAN	32	376	32	123	253
[09] CIREBON	40	424	40	312	112
[10] MAJALENGKA	26	343	26	123	220
[11] SUMEDANG	26	277	26	77	200
[12] INDRAMAYU	31	317	31	110	207
[13] SUBANG	30	253	30	53	200
[14] PURWAKARTA	17	192	17	73	119
[15] KARAWANG	30	309	30	126	183
[16] BEKASI	23	187	23	101	86
[17] BANDUNG BARAT	16	165	16	81	84
[18] PANGANDARAN	10	93	10	12	81
[71] BOGOR	6	68	6	68	0
[72] SUKABUMI	7	33	7	33	0
[73] BANDUNG	30	151	30	151	0
[74] CIREBON	5	22	5	22	0
[75] BEKASI	12	56	12	56	0
[76] DEPOK	11	63	11	63	0
[77] CIMAHI	3	15	3	15	0
[78] TASIKMALAYA	10	69	10	61	8
[79] BANJAR	4	25	4	13	12
JAWA BARAT	**627**	**5 957**	**627**	**2 672**	**3 285**

https://jabar.bps.go.id

https://jabar.bps.go.id

KABUPATEN BOGOR

https://jabar.bps.go.id

https://jabar.bps.go.id

PROVINSI : [32] JAWA BARAT
KAB/KOTA : [01] BOGOR

Data Kemendagri			MFD 2021 Semester 2		
No	**Kode**	**Nama Kecamatan**	**No**	**Kode**	**Nama Kecamatan**
1	32.01.21	NANGGUNG	1	3201010	NANGGUNG
2	32.01.14	LEUWILIANG	2	3201020	LEUWILIANG
3	32.01.39	LEUWISADENG	3	3201021	LEUWISADENG
4	32.01.17	PAMIJAHAN	4	3201030	PAMIJAHAN
5	32.01.16	CIBUNGBULANG	5	3201040	CIBUNGBULANG
6	32.01.15	CIAMPEA	6	3201050	CIAMPEA
7	32.01.40	TENJOLAYA	7	3201051	TENJOLAYA
8	32.01.30	DRAMAGA	8	3201060	DRAMAGA
9	32.01.29	CIOMAS	9	3201070	CIOMAS
10	32.01.31	TAMANSARI	10	3201071	TAMANSARI
11	32.01.28	CIJERUK	11	3201080	CIJERUK
12	32.01.38	CIGOMBONG	12	3201081	CIGOMBONG
13	32.01.27	CARINGIN	13	3201090	CARINGIN
14	32.01.24	CIAWI	14	3201100	CIAWI
15	32.01.25	CISARUA	15	3201110	CISARUA
16	32.01.26	MEGAMENDUNG	16	3201120	MEGAMENDUNG
17	32.01.04	SUKARAJA	17	3201130	SUKARAJA
18	32.01.05	BABAKAN MADANG	18	3201140	BABAKAN MADANG
19	32.01.09	SUKAMAKMUR	19	3201150	SUKAMAKMUR
20	32.01.08	CARIU	20	3201160	CARIU
21	32.01.36	TANJUNGSARI	21	3201161	TANJUNGSARI
22	32.01.06	JONGGOL	22	3201170	JONGGOL
23	32.01.07	CILEUNGSI	23	3201180	CILEUNGSI
24	32.01.32	KLAPANUNGGAL	24	3201181	KLAPANUNGGAL

https://jabar.bps.go.id

KODE DAN NAMA KECAMATAN

PROVINSI : [32] JAWA BARAT
KAB/KOTA : [01] BOGOR

Data Kemendagri			MFD 2021 Semester 2		
No	Kode	Nama Kecamatan	No	Kode	Nama Kecamatan
25	32.01.02	GUNUNG PUTRI	25	3201190	GUNUNG PUTRI
26	32.01.03	CITEUREUP	26	3201200	CITEUREUP
27	32.01.01	CIBINONG	27	3201210	CIBINONG
28	32.01.13	BOJONG GEDE	28	3201220	BOJONG GEDE
29	32.01.37	TAJURHALANG	29	3201221	TAJUR HALANG
30	32.01.12	KEMANG	30	3201230	KEMANG
31	32.01.34	RANCA BUNGUR	31	3201231	RANCABUNGUR
32	32.01.10	PARUNG	32	3201240	PARUNG
33	32.01.33	CISEENG	33	3201241	CISEENG
34	32.01.11	GUNUNG SINDUR	34	3201250	GUNUNG SINDUR
35	32.01.18	RUMPIN	35	3201260	RUMPIN
36	32.01.22	CIGUDEG	36	3201270	CIGUDEG
37	32.01.35	SUKAJAYA	37	3201271	SUKAJAYA
38	32.01.19	JASINGA	38	3201280	JASINGA
39	32.01.23	TENJO	39	3201290	TENJO
40	32.01.20	PARUNG PANJANG	40	3201300	PARUNG PANJANG

https://jabar.bps.go.id

JUMLAH DESA/KELURAHAN PER KECAMATAN

PROVINSI : [32] JAWA BARAT
KAB/KOTA : [01] BOGOR

Data Kemendagri				MFD 2021 Semester 2			
No	Kode	Nama Kecamatan	Jml Desa	No	Kode	Nama Kecamatan	Jml Desa
1	32.01.21	NANGGUNG	11	1	3201010	NANGGUNG	11
2	32.01.14	LEUWILIANG	11	2	3201020	LEUWILIANG	11
3	32.01.39	LEUWISADENG	8	3	3201021	LEUWISADENG	8
4	32.01.17	PAMIJAHAN	15	4	3201030	PAMIJAHAN	15
5	32.01.16	CIBUNGBULANG	15	5	3201040	CIBUNGBULANG	15
6	32.01.15	CIAMPEA	13	6	3201050	CIAMPEA	13
7	32.01.40	TENJOLAYA	7	7	3201051	TENJOLAYA	7
8	32.01.30	DRAMAGA	10	8	3201060	DRAMAGA	10
9	32.01.29	CIOMAS	11	9	3201070	CIOMAS	11
10	32.01.31	TAMANSARI	8	10	3201071	TAMANSARI	8
11	32.01.28	CIJERUK	9	11	3201080	CIJERUK	9
12	32.01.38	CIGOMBONG	9	12	3201081	CIGOMBONG	9
13	32.01.27	CARINGIN	12	13	3201090	CARINGIN	12
14	32.01.24	CIAWI	13	14	3201100	CIAWI	13
15	32.01.25	CISARUA	10	15	3201110	CISARUA	10
16	32.01.26	MEGAMEN-DUNG	12	16	3201120	MEGAMEN-DUNG	12
17	32.01.04	SUKARAJA	13	17	3201130	SUKARAJA	13
18	32.01.05	BABAKAN MADANG	9	18	3201140	BABAKAN MADANG	9
19	32.01.09	SUKAMAKMUR	10	19	3201150	SUKAMAKMUR	10
20	32.01.08	CARIU	10	20	3201160	CARIU	10

https://jabar.bps.go.id

JUMLAH DESA/KELURAHAN PER KECAMATAN

PROVINSI : [32] JAWA BARAT
KAB/KOTA : [01] BOGOR

Data Kemendagri				MFD 2021 Semester 2			
No	Kode	Nama Kecamatan	Jml Desa	No	Kode	Nama Kecamatan	Jml Desa
21	32.01.36	TANJUNGSARI	10	21	3201161	TANJUNGSARI	10
22	32.01.06	JONGGOL	14	22	3201170	JONGGOL	14
23	32.01.07	CILEUNGSI	12	23	3201180	CILEUNGSI	12
24	32.01.32	KLAPANUNG-GAL	9	24	3201181	KLAPANUNG-GAL	9
25	32.01.02	GUNUNG PUTRI	10	25	3201190	GUNUNG PUTRI	10
26	32.01.03	CITEUREUP	14	26	3201200	CITEUREUP	14
27	32.01.01	CIBINONG	13	27	3201210	CIBINONG	13
28	32.01.13	BOJONG GEDE	9	28	3201220	BOJONG GEDE	9
29	32.01.37	TAJURHALANG	7	29	3201221	TAJUR HALANG	7
30	32.01.12	KEMANG	9	30	3201230	KEMANG	9
31	32.01.34	RANCA BUNGUR	7	31	3201231	RANCABUNGUR	7
32	32.01.10	PARUNG	9	32	3201240	PARUNG	9
33	32.01.33	CISEENG	10	33	3201241	CISEENG	10
34	32.01.11	GUNUNG SIN-DUR	10	34	3201250	GUNUNG SIN-DUR	10
35	32.01.18	RUMPIN	14	35	3201260	RUMPIN	14
36	32.01.22	CIGUDEG	15	36	3201270	CIGUDEG	15
37	32.01.35	SUKAJAYA	11	37	3201271	SUKAJAYA	11
38	32.01.19	JASINGA	16	38	3201280	JASINGA	16
39	32.01.23	TENJO	9	39	3201290	TENJO	9
40	32.01.20	PARUNG PAN-JANG	11	40	3201300	PARUNG PAN-JANG	11

https://jabar.bps.go.id

PROVINSI : [32] JAWA BARAT
KAB/KOTA : [01] BOGOR
KECAMATAN : [010] NANGGUNG

Data Kemendagri			MFD 2021 Semester 2			
No	Kode	Nama Desa	No	Kode	Nama Desa	Status*
1	32.01.21.2001	MALASARI	1	3201010001	MALASARI	2
2	32.01.21.2004	BANTARKARET	2	3201010002	BANTAR KARET	2
3	32.01.21.2003	CISARUA	3	3201010003	CISARUA	2
4	32.01.21.2002	CURUGBITUNG	4	3201010004	CURUG BITUNG	2
5	32.01.21.2007	NANGGUNG	5	3201010005	NANGGUNG	1
6	32.01.21.2009	PANGKALJAYA	6	3201010006	PANGKAL JAYA	2
7	32.01.21.2010	SUKALUYU	7	3201010007	SUKALUYU	1
8	32.01.21.2005	HAMBARO	8	3201010008	HAMBARO	2
9	32.01.21.2006	KALONGLIUD	9	3201010009	KALONG LIUD	1
10	32.01.21.2008	PARAKANMUN-CANG	10	3201010010	PARAKAN MUN-CANG	1
11	32.01.21.2011	BATU TULIS	11	3201010011	BATU TULIS	1

https://jabar.bps.go.id

Catatan :
*) 1. Perkotaan
2. Perdesaan

DAFTAR DESA/KELURAHAN

PROVINSI : [32] JAWA BARAT
KAB/KOTA : [01] BOGOR
KECAMATAN : [020] LEUWILIANG

Data Kemendagri			MFD 2021 Semester 2			
No	Kode	Nama Desa	No	Kode	Nama Desa	Status*
1	32.01.14.2002	PURASARI	1	3201020001	PURASARI	2
2	32.01.14.2008	PURASEDA	2	3201020002	PURASEDA	2
3	32.01.14.2003	KARYASARI	3	3201020003	KARYASARI	1
4	32.01.14.2004	PABANGBON	4	3201020004	PABANGBON	2
5	32.01.14.2005	KARACAK	5	3201020005	KARACAK	2
6	32.01.14.2006	BARENGKOK	6	3201020006	BARENGKOK	1
7	32.01.14.2010	CIBEBER II	7	3201020007	CIBEBER II	1
8	32.01.14.2009	CIBEBER I	8	3201020016	CIBEBER I	1
9	32.01.14.2007	LEUWIMEKAR	9	3201020017	LEUWIMEKAR	1
10	32.01.14.2001	LEUWILIANG	10	3201020018	LEUWILIANG	1
11	32.01.14.2011	KAREHKEL	11	3201020019	KAREHKEL	1

Catatan :
*) 1. Perkotaan
2. Perdesaan

https://jabar.bps.go.id

PROVINSI : [32] JAWA BARAT
KAB/KOTA : [01] BOGOR
KECAMATAN : [021] LEUWISADENG

Data Kemendagri			MFD 2021 Semester 2			
No	Kode	Nama Desa	No	Kode	Nama Desa	Status*
1	32.01.39.2004	WANGUN JAYA	1	3201021001	WANGUN JAYA	2
2	32.01.39.2003	SADENGKOLOT	2	3201021002	SADENGKOLOT	1
3	32.01.39.2001	LEUWISADENG	3	3201021003	LEUWISADENG	1
4	32.01.39.2008	SIBANTENG	4	3201021004	SIBANTENG	1
5	32.01.39.2002	BABAKAN SADENG	5	3201021005	BABAKAN SADENG	2
6	32.01.39.2007	SADENG	6	3201021006	SADENG	1
7	32.01.39.2006	KALONG II	7	3201021007	KALONG II	1
8	32.01.39.2005	KALONG I	8	3201021008	KALONG I	1

Catatan :
*) 1. Perkotaan
2. Perdesaan

https://jabar.bps.go.id

DAFTAR DESA/KELURAHAN

PROVINSI : [32] JAWA BARAT
KAB/KOTA : [01] BOGOR
KECAMATAN : [030] PAMIJAHAN

Data Kemendagri			MFD 2021 Semester 2			
No	Kode	Nama Desa	No	Kode	Nama Desa	Status*
1	32.01.17.2002	CIBUNIAN	1	3201030001	CIBUNIAN	2
2	32.01.17.2001	PURWABAKTI	2	3201030002	PURWABAKTI	2
3	32.01.17.2015	CIASMARA	3	3201030003	CIASMARA	1
4	32.01.17.2013	CIASIHAN	4	3201030004	CIASIHAN	1
5	32.01.17.2014	GUNUNG SARI	5	3201030005	GUNUNG SARI	1
6	32.01.17.2005	GUNUNG BUNDER II	6	3201030006	GUNUNG BUNDER II	2
7	32.01.17.2010	GUNUNG BUNDER I	7	3201030007	GUNUNG BUNDER I	1
8	32.01.17.2009	CIBENING	8	3201030008	CIBENING	1
9	32.01.17.2012	GUNUNG PICUNG	9	3201030009	GUNUNG PICUNG	1
10	32.01.17.2011	CIBITUNG KULON	10	3201030010	CIBITUNG KULON	2
11	32.01.17.2003	CIBITUNG WETAN	11	3201030011	CIBITUNG WETAN	1
12	32.01.17.2008	PAMIJAHAN	12	3201030012	PAMIJAHAN	1
13	32.01.17.2006	PASAREAN	13	3201030013	PASAREAN	1
14	32.01.17.2004	GUNUNG MENYAN	14	3201030014	GUNUNG MENYAN	1
15	32.01.17.2007	CIMAYANG	15	3201030015	CIMAYANG	1

Catatan :
*) 1. Perkotaan
2. Perdesaan

https://jabar.bps.go.id

PROVINSI : [32] JAWA BARAT
KAB/KOTA : [01] BOGOR
KECAMATAN : [040] CIBUNGBULANG

Data Kemendagri			MFD 2021 Semester 2			
No	Kode	Nama Desa	No	Kode	Nama Desa	Status*
1	32.01.16.2001	SITU UDIK	1	3201040001	SITU UDIK	1
2	32.01.16.2002	SITU ILIR	2	3201040002	SITU ILIR	1
3	32.01.16.2008	CIBATOK 2	3	3201040003	CIBATOK 2	1
4	32.01.16.2005	CIARUTEN UDIK	4	3201040004	CIARUTEN UDIK	1
5	32.01.16.2004	CIBATOK 1	5	3201040005	CIBATOK 1	1
6	32.01.16.2013	SUKAMAJU	6	3201040006	SUKAMAJU	1
7	32.01.16.2003	CEMPLANG	7	3201040007	CEMPLANG	1
8	32.01.16.2014	GALUGA	8	3201040008	GALUGA	1
9	32.01.16.2009	DUKUH	9	3201040009	DUKUH	1
10	32.01.16.2012	CIMANGGU 2	10	3201040010	CIMANGGU 2	1
11	32.01.16.2007	CIMANGGU 1	11	3201040011	CIMANGGU 1	1
12	32.01.16.2015	GIRIMULYA	12	3201040012	GIRIMULYA	1
13	32.01.16.2006	LEUWEUNG KOLOT	13	3201040013	LEUWEUNG KOLOT	1
14	32.01.16.2011	CIARUTEUN ILIR	14	3201040014	CIARUTEN ILIR	2
15	32.01.16.2010	CIJUJUNG	15	3201040015	CIJUJUNG	2

Catatan :
*) 1. Perkotaan
2. Perdesaan

https://jabar.bps.go.id

DAFTAR DESA/KELURAHAN

PROVINSI : [32] JAWA BARAT
KAB/KOTA : [01] BOGOR
KECAMATAN : [050] CIAMPEA

Data Kemendagri			MFD 2021 Semester 2			
No	Kode	Nama Desa	No	Kode	Nama Desa	Status*
1	32.01.15.2013	CIAMPEA UDIK	1	3201050004	CIAMPEA UDIK	1
2	32.01.15.2002	CINANGKA	2	3201050008	CINANGKA	1
3	32.01.15.2006	CIBUNTU	3	3201050009	CIBUNTU	1
4	32.01.15.2007	CICADAS	4	3201050010	CICADAS	1
5	32.01.15.2005	TEGAL WARU	5	3201050011	TEGAL WARU	2
6	32.01.15.2004	BOJONG JENG-KOL	6	3201050012	BOJONG JENG-KOL	1
7	32.01.15.2003	CIHIDEUNG UDIK	7	3201050013	CIHIDEUNG UDIK	1
8	32.01.15.2010	CIHIDEUNG ILIR	8	3201050014	CIHIDEUNG ILIR	1
9	32.01.15.2011	CIBANTENG	9	3201050015	CIBANTENG	1
10	32.01.15.2009	BOJONG RANG-KAS	10	3201050016	BOJONG RANGKAS	1
11	32.01.15.2008	CIBADAK	11	3201050017	CIBADAK	1
12	32.01.15.2012	BENTENG	12	3201050018	BENTENG	1
13	32.01.15.2001	CIAMPEA	13	3201050019	CIAMPEA	1

Catatan :
*) 1. Perkotaan
2. Perdesaan

https://jabar.bps.go.id

PROVINSI : [32] JAWA BARAT
KAB/KOTA : [01] BOGOR
KECAMATAN : [051] TENJOLAYA

Data Kemendagri			MFD 2021 Semester 2			
No	Kode	Nama Desa	No	Kode	Nama Desa	Status*
1	32.01.40.2001	TAPOS I	1	3201051001	TAPOS I	1
2	32.01.40.2006	GUNUNG MALANG	2	3201051002	GUNUNG MALANG	2
3	32.01.40.2002	TAPOS II	3	3201051003	TAPOS II	1
4	32.01.40.2004	SITU DAUN	4	3201051004	SITU DAUN	1
5	32.01.40.2003	CIBITUNG TENGAH	5	3201051005	CIBITUNG TENGAH	1
6	32.01.40.2005	CINANGNENG	6	3201051006	CINANGNENG	1
7	32.01.40.2007	GUNUNG MULYA	7	3201051007	GUNUNG MULYA	2

Catatan :
*) 1. Perkotaan
2. Perdesaan

https://jabar.bps.go.id

DAFTAR DESA/KELURAHAN

PROVINSI : [32] JAWA BARAT
KAB/KOTA : [01] BOGOR
KECAMATAN : [060] DRAMAGA

Data Kemendagri			MFD 2021 Semester 2			
No	Kode	Nama Desa	No	Kode	Nama Desa	Status*
1	32.01.30.2006	PURWASARI	1	3201060001	PURWASARI	2
2	32.01.30.2005	PETIR	2	3201060002	PETIR	1
3	32.01.30.2001	SUKADAMAI	3	3201060003	SUKADAMAI	2
4	32.01.30.2004	SUKAWENING	4	3201060004	SUKAWENING	1
5	32.01.30.2010	NEGLASARI	5	3201060005	NEGLASARI	1
6	32.01.30.2003	SINARSARI	6	3201060006	SINARSARI	1
7	32.01.30.2002	CIHERANG	7	3201060007	CIHERANG	1
8	32.01.30.2009	DRAMAGA	8	3201060008	DRAMAGA	1
9	32.01.30.2008	BABAKAN	9	3201060009	BABAKAN	1
10	32.01.30.2007	CIKARAWANG	10	3201060010	CIKARAWANG	1

https://jabar.bps.go.id

Catatan :
*) 1. Perkotaan
2. Perdesaan

PROVINSI : [32] JAWA BARAT
KAB/KOTA : [01] BOGOR
KECAMATAN : [070] CIOMAS

Data Kemendagri			MFD 2021 Semester 2			
No	Kode	Nama Desa	No	Kode	Nama Desa	Status*
1	32.01.29.2009	KOTA BATU	1	3201070009	KOTA BATU	1
2	32.01.29.2001	MEKARJAYA	2	3201070010	MEKARJAYA	1
3	32.01.29.2004	PARAKAN	3	3201070011	PARAKAN	1
4	32.01.29.2005	CIOMAS	4	3201070012	CIOMAS	1
5	32.01.29.2006	PAGELARAN	5	3201070013	PAGELARAN	1
6	32.01.29.2007	SUKAMAKMUR	6	3201070014	SUKAMAKMUR	1
7	32.01.29.2008	CIAPUS	7	3201070015	CIAPUS	1
8	32.01.29.2002	SUKAHARJA	8	3201070016	SUKAHARJA	1
9	32.01.29.1003	PADASUKA	9	3201070017	PADASUKA	1
10	32.01.29.2011	CIOMAS RA-HAYU	10	3201070018	CIOMAS RA-HAYU	1
11	32.01.29.2010	LALADON	11	3201070019	LALADON	1

Catatan :
*) 1. Perkotaan
2. Perdesaan

https://jabar.bps.go.id

DAFTAR DESA/KELURAHAN

PROVINSI : [32] JAWA BARAT
KAB/KOTA : [01] BOGOR
KECAMATAN : [071] TAMANSARI

Data Kemendagri			MFD 2021 Semester 2			
No	Kode	Nama Desa	No	Kode	Nama Desa	Status*
1	32.01.31.2008	SUKAJADI	1	3201071001	SUKAJADI	2
2	32.01.31.2005	SUKALUYU	2	3201071002	SUKALUYU	2
3	32.01.31.2007	SUKAJAYA	3	3201071003	SUKAJAYA	2
4	32.01.31.2006	SUKARESMI	4	3201071004	SUKARESMI	2
5	32.01.31.2003	PASIR EURIH	5	3201071005	PASIR EURIH	1
6	32.01.31.2004	TAMAN SARI	6	3201071006	TAMAN SARI	1
7	32.01.31.2001	SUKAMANTRI	7	3201071007	SUKAMANTRI	1
8	32.01.31.2002	SIRNAGALIH	8	3201071008	SIIRNAGALIH	1

Catatan :
*) 1. Perkotaan
2. Perdesaan

https://jabar.bps.go.id

PROVINSI : [32] JAWA BARAT
KAB/KOTA : [01] BOGOR
KECAMATAN : [080] CIJERUK

Data Kemendagri			MFD 2021 Semester 2			
No	Kode	Nama Desa	No	Kode	Nama Desa	Status*
1	32.01.28.2003	WARUNG MEN-TENG	1	3201080010	WARUNG MEN-TENG	1
2	32.01.28.2001	CIJERUK	2	3201080011	CIJERUK	2
3	32.01.28.2002	CIPELANG	3	3201080012	CIPELANG	1
4	32.01.28.2006	CIBALUNG	4	3201080013	CIBALUNG	2
5	32.01.28.2005	CIPICUNG	5	3201080014	CIPICUNG	2
6	32.01.28.2009	TANJUNG SARI	6	3201080015	TANJUNG SARI	2
7	32.01.28.2004	TAJUR HALANG	7	3201080016	TAJUR HALANG	2
8	32.01.28.2008	PALASARI	8	3201080017	PALASARI	1
9	32.01.28.2007	SUKAHARJA	9	3201080018	SUKAHARJA	1

Catatan :
*) 1. Perkotaan
2. Perdesaan

https://jabar.bps.go.id

DAFTAR DESA/KELURAHAN

PROVINSI : [32] JAWA BARAT
KAB/KOTA : [01] BOGOR
KECAMATAN : [081] CIGOMBONG

Data Kemendagri			MFD 2021 Semester 2			
No	Kode	Nama Desa	No	Kode	Nama Desa	Status*
1	32.01.38.2006	TUGU JAYA	1	3201081001	TUGU JAYA	1
2	32.01.38.2001	CIGOMBONG	2	3201081002	CIGOMBONG	1
3	32.01.38.2002	WATES JAYA	3	3201081003	WATESJAYA	1
4	32.01.38.2004	SROGOL	4	3201081004	SROGOL	1
5	32.01.38.2003	CIBURUY	5	3201081005	CIBURUY	1
6	32.01.38.2005	CISALADA	6	3201081006	CISALADA	1
7	32.01.38.2007	PASIR JAYA	7	3201081007	PASIRJAYA	1
8	32.01.38.2008	CIBURAYUT	8	3201081008	CIBURAYUT	2
9	32.01.38.2009	CIADEG	9	3201081009	CIADEG	1

Catatan :
*) 1. Perkotaan
2. Perdesaan

https://jabar.bps.go.id

PROVINSI : [32] JAWA BARAT
KAB/KOTA : [01] BOGOR
KECAMATAN : [090] CARINGIN

Data Kemendagri			MFD 2021 Semester 2			
No	Kode	Nama Desa	No	Kode	Nama Desa	Status*
1	32.01.27.2010	PASIR BUNCIR	1	3201090001	PASIR BUNCIR	1
2	32.01.27.2006	CINAGARA	2	3201090002	CINAGARA	1
3	32.01.27.2012	TANGKIL	3	3201090003	TANGKIL	2
4	32.01.27.2001	PASIR MUN-CANG	4	3201090004	PASIR MUN-CANG	1
5	32.01.27.2009	MUARA JAYA	5	3201090005	MUARA JAYA	1
6	32.01.27.2004	CARINGIN	6	3201090006	CARINGIN	1
7	32.01.27.2011	LEMAH DUHUR	7	3201090007	LEMAH DUHUR	2
8	32.01.27.2007	CIMANDE	8	3201090008	CIMANDE	2
9	32.01.27.2008	PANCAWATI	9	3201090009	PANCAWATI	1
10	32.01.27.2003	CIDERUM	10	3201090010	CIDERUM	1
11	32.01.27.2005	CIHERANG PONDOK	11	3201090011	CIHERANG PONDOK	1
12	32.01.27.2002	CIMANDE HILIR	12	3201090012	CIMANDE HILIR	1

Catatan :
*) 1. Perkotaan
2. Perdesaan

https://jabar.bps.go.id

DAFTAR DESA/KELURAHAN

PROVINSI : [32] JAWA BARAT
KAB/KOTA : [01] BOGOR
KECAMATAN : [100] CIAWI

Data Kemendagri			MFD 2021 Semester 2			
No	Kode	Nama Desa	No	Kode	Nama Desa	Status*
1	32.01.24.2001	CILEUNGSI	1	3201100001	CILEUNGSI	1
2	32.01.24.2002	CITAPEN	2	3201100002	CITAPEN	1
3	32.01.24.2003	CIBEDUG	3	3201100003	CIBEDUG	1
4	32.01.24.2010	BOJONG MURNI	4	3201100004	BOJONG MURNI	2
5	32.01.24.2004	JAMBU LUWUK	5	3201100005	JAMBU LUWUK	1
6	32.01.24.2005	BANJAR SARI	6	3201100006	BANJAR SARI	1
7	32.01.24.2011	BANJAR WANGI	7	3201100007	BANJAR WANGI	1
8	32.01.24.2013	BITUNG SARI	8	3201100008	BITUNG SARI	1
9	32.01.24.2006	TELUK PINANG	9	3201100009	TELUK PINANG	1
10	32.01.24.2007	BANJAR WARU	10	3201100010	BANJAR WARU	1
11	32.01.24.2012	CIAWI	11	3201100011	CIAWI	1
12	32.01.24.2008	BENDUNGAN	12	3201100012	BENDUNGAN	1
13	32.01.24.2009	PANDANSARI	13	3201100013	PANDANSARI	1

Catatan :
*) 1. Perkotaan
2. Perdesaan

https://jabar.bps.go.id

PROVINSI : [32] JAWA BARAT
KAB/KOTA : [01] BOGOR
KECAMATAN : [110] CISARUA

Data Kemendagri			MFD 2021 Semester 2			
No	Kode	Nama Desa	No	Kode	Nama Desa	Status*
1	32.01.25.2005	CITEKO	1	3201110001	CITEKO	1
2	32.01.25.2003	CIBEUREUM	2	3201110002	CIBEUREUM	1
3	32.01.25.2006	TUGU SELATAN	3	3201110003	TUGU SELATAN	1
4	32.01.25.2009	TUGU UTARA	4	3201110004	TUGU UTARA	1
5	32.01.25.2001	BATU LAYANG	5	3201110005	BATU LAYANG	1
6	32.01.25.1010	CISARUA	6	3201110006	CISARUA	1
7	32.01.25.2008	KOPO	7	3201110007	KOPO	1
8	32.01.25.2007	LEUWIMALANG	8	3201110008	LEUWIMALANG	1
9	32.01.25.2002	JOGJOGAN	9	3201110009	JOGJOGAN	1
10	32.01.25.2004	CILEMBER	10	3201110010	CILEMBER	1

https://jabar.bps.go.id

Catatan :
*) 1. Perkotaan
2. Perdesaan

DAFTAR DESA/KELURAHAN

PROVINSI : [32] JAWA BARAT
KAB/KOTA : [01] BOGOR
KECAMATAN : [120] MEGAMENDUNG

Data Kemendagri			MFD 2021 Semester 2			
No	Kode	Nama Desa	No	Kode	Nama Desa	Status*
1	32.01.26.2011	SUKARESMI	1	3201120001	SUKARESMI	1
2	32.01.26.2008	SUKAGALIH	2	3201120002	SUKAGALIH	1
3	32.01.26.2002	KUTA	3	3201120003	KUTA	1
4	32.01.26.2004	SUKAKARYA	4	3201120004	SUKAKARYA	1
5	32.01.26.2007	SUKAMANAH	5	3201120005	SUKAMANAH	1
6	32.01.26.2001	SUKAMAJU	6	3201120006	SUKAMAJU	1
7	32.01.26.2010	SUKAMAHI	7	3201120007	SUKAMAHI	1
8	32.01.26.2003	GADOG	8	3201120008	GADOG	1
9	32.01.26.2006	CIPAYUNG DATAR	9	3201120009	CIPAYUNG	1
10	32.01.26.2009	CIPAYUNG GIRANG	10	3201120010	CIPAYUNG GIRANG	1
11	32.01.26.2005	MEGAMEN-DUNG	11	3201120011	MEGAMEN-DUNG	1
12	32.01.26.2012	PASIR ANGIN	12	3201120012	PASIR ANGIN	1

Catatan :
*) 1. Perkotaan
2. Perdesaan

https://jabar.bps.go.id

PROVINSI : [32] JAWA BARAT
KAB/KOTA : [01] BOGOR
KECAMATAN : [130] SUKARAJA

Data Kemendagri			MFD 2021 Semester 2			
No	Kode	Nama Desa	No	Kode	Nama Desa	Status*
1	32.01.04.2004	CIBANON	1	3201130001	CIBANON	2
2	32.01.04.2001	GUNUNGGEULIS	2	3201130002	GUNUNG GEULIS	2
3	32.01.04.2005	NAGRAK	3	3201130003	NAGRAK	1
4	32.01.04.2006	SUKATANI	4	3201130004	SUKATANI	1
5	32.01.04.2007	SUKARAJA	5	3201130005	SUKARAJA	1
6	32.01.04.2008	CIKEAS	6	3201130006	CIKEAS	1
7	32.01.04.2012	CADASNGAM-PAR	7	3201130007	CADAS NGAM-PAR	1
8	32.01.04.2013	PASIRLAYA	8	3201130008	PASIRLAJA	1
9	32.01.04.2011	CIJUJUNG	9	3201130009	CIJUJUNG	1
10	32.01.04.2010	CIMANDALA	10	3201130010	CIMANDALA	1
11	32.01.04.2009	PASIR JAMBU	11	3201130011	PASIR JAMBU	1
12	32.01.04.2002	CILEBUT TIMUR	12	3201130012	CILEBUT TIMUR	1
13	32.01.04.2003	CILEBUT BARAT	13	3201130013	CILEBUT BARAT	1

Catatan :
*) 1. Perkotaan
2. Perdesaan

https://jabar.bps.go.id

DAFTAR DESA/KELURAHAN

PROVINSI : [32] JAWA BARAT
KAB/KOTA : [01] BOGOR
KECAMATAN : [140] BABAKAN MADANG

Data Kemendagri			MFD 2021 Semester 2			
No	Kode	Nama Desa	No	Kode	Nama Desa	Status*
1	32.01.05.2001	CIJAYANTI	1	3201140001	CIJAYANTI	2
2	32.01.05.2009	BOJONG KONENG	2	3201140002	BOJONG KONENG	2
3	32.01.05.2004	KARANG TENGAH	3	3201140003	KARANG TENGAH	2
4	32.01.05.2002	SUMUR BATU	4	3201140004	SUMUR BATU	2
5	32.01.05.2008	BABAKAN MADANG	5	3201140005	BABAKAN MADANG	1
6	32.01.05.2007	CITARINGGUL	6	3201140006	CITARINGGUL	1
7	32.01.05.2005	CIPAMBUAN	7	3201140007	CIPAMBUAN	1
8	32.01.05.2006	KADUMANGU	8	3201140008	KADUMANGU	1
9	32.01.05.2003	SENTUL	9	3201140009	SENTUL	1

Catatan :
*) 1. Perkotaan
2. Perdesaan

https://jabar.bps.go.id

PROVINSI : [32] JAWA BARAT
KAB/KOTA : [01] BOGOR
KECAMATAN : [150] SUKAMAKMUR

Data Kemendagri			MFD 2021 Semester 2			
No	Kode	Nama Desa	No	Kode	Nama Desa	Status*
1	32.01.09.2004	SUKAWANGI	1	3201150001	SUKAWANGI	2
2	32.01.09.2008	SUKAHARJA	2	3201150002	SUKAHARJA	2
3	32.01.09.2001	WARGAJAYA	3	3201150003	WARGAJAYA	2
4	32.01.09.2009	SIRNAJAYA	4	3201150004	SIRNAJAYA	2
5	32.01.09.2007	SUKAMULYA	5	3201150005	SUKAMULYA	1
6	32.01.09.2010	SUKAMAKMUR	6	3201150006	SUKAMAKMUR	1
7	32.01.09.2005	CIBADAK	7	3201150007	CIBADAK	1
8	32.01.09.2002	PABUARAN	8	3201150008	PABUARAN	1
9	32.01.09.2003	SUKADAMAI	9	3201150009	SUKADAMAI	1
10	32.01.09.2006	SUKARESMI	10	3201150010	SUKARESMI	2

https://jabar.bps.go.id

Catatan :
*) 1. Perkotaan
2. Perdesaan

DAFTAR DESA/KELURAHAN

PROVINSI : [32] JAWA BARAT
KAB/KOTA : [01] BOGOR
KECAMATAN : [160] CARIU

Data Kemendagri			MFD 2021 Semester 2			
No	Kode	Nama Desa	No	Kode	Nama Desa	Status*
1	32.01.08.2001	KARYA MEKAR	1	3201160011	KARYA MEKAR	2
2	32.01.08.2007	BANTARKU-NING	2	3201160012	BANTAR KUNING	2
3	32.01.08.2003	CIKUTAMAHI	3	3201160013	CIKUTAMAHI	2
4	32.01.08.2010	CIBATUTIGA	4	3201160014	CIBATU TIGA	2
5	32.01.08.2006	MEKARWANGI	5	3201160015	MEKARWANGI	2
6	32.01.08.2009	TEGALPAN-JANG	6	3201160016	TEGAL PAN-JANG	1
7	32.01.08.2005	CARIU	7	3201160017	CARIU	1
8	32.01.08.2004	KUTAMEKAR	8	3201160018	KUTAMEKAR	2
9	32.01.08.2008	SUKAJADI	9	3201160019	SUKAJADI	2
10	32.01.08.2002	BABAKANRA-DEN	10	3201160020	BABAKAN RADEN	2

Catatan :
*) 1. Perkotaan
2. Perdesaan

https://jabar.bps.go.id

PROVINSI : [32] JAWA BARAT
KAB/KOTA : [01] BOGOR
KECAMATAN : [161] TANJUNGSARI

Data Kemendagri			MFD 2021 Semester 2			
No	Kode	Nama Desa	No	Kode	Nama Desa	Status*
1	32.01.36.2006	CIBADAK	1	3201161001	CIBADAK	2
2	32.01.36.2001	TANJUNG SARI	2	3201161002	TANJUNG SARI	2
3	32.01.36.2008	SINARSARI	3	3201161003	SINARSARI	1
4	32.01.36.2010	SINARRASA	4	3201161004	SINARRASA	2
5	32.01.36.2009	BUANAJAYA	5	3201161005	BUANAJAYA	2
6	32.01.36.2004	ANTAJAYA	6	3201161006	ANTAJAYA	2
7	32.01.36.2005	PASIR TANJUNG	7	3201161007	PASIR TANJUNG	2
8	32.01.36.2003	TANJUNG RASA	8	3201161008	TANJUNG RASA	2
9	32.01.36.2007	SUKARASA	9	3201161009	SUKARASA	2
10	32.01.36.2002	SELAWANGI	10	3201161010	SELAWANGI	2

https://jabar.bps.go.id

Catatan :
*) 1. Perkotaan
2. Perdesaan

DAFTAR DESA/KELURAHAN

PROVINSI : [32] JAWA BARAT
KAB/KOTA : [01] BOGOR
KECAMATAN : [170] JONGGOL

Data Kemendagri			MFD 2021 Semester 2			
No	Kode	Nama Desa	No	Kode	Nama Desa	Status*
1	32.01.06.2013	SUKAJAYA	1	3201170001	SUKAJAYA	2
2	32.01.06.2005	SUKANEGARA	2	3201170002	SUKANEGARA	1
3	32.01.06.2008	CIBODAS	3	3201170003	CIBODAS	2
4	32.01.06.2011	SINGASARI	4	3201170004	SINGASARI	2
5	32.01.06.2003	SINGAJAYA	5	3201170005	SINGAJAYA	1
6	32.01.06.2004	SUKASIRNA	6	3201170006	SUKASIRNA	1
7	32.01.06.2012	BALEKAMBANG	7	3201170007	BALEKAMBANG	2
8	32.01.06.2010	BENDUNGAN	8	3201170008	BENDUNGAN	1
9	32.01.06.2002	SIRNAGALIH	9	3201170009	SIRNAGALIH	2
10	32.01.06.2009	JONGGOL	10	3201170010	JONGGOL	1
11	32.01.06.2001	SUKAMAJU	11	3201170011	SUKAMAJU	1
12	32.01.06.2006	SUKAMANAH	12	3201170012	SUKAMANAH	1
13	32.01.06.2007	WENINGGALIH	13	3201170013	WENINGGALIH	2
14	32.01.06.2014	SUKAGALIH	14	3201170014	SUKAGALIH	2

Catatan :
*) 1. Perkotaan
2. Perdesaan

https://jabar.bps.go.id

PROVINSI : [32] JAWA BARAT
KAB/KOTA : [01] BOGOR
KECAMATAN : [180] CILEUNGSI

Data Kemendagri			MFD 2021 Semester 2			
No	Kode	Nama Desa	No	Kode	Nama Desa	Status*
1	32.01.07.2004	DAYEUH	1	3201180010	DAYEUH	1
2	32.01.07.2003	MAMPIR	2	3201180011	MAMPIR	1
3	32.01.07.2009	SITUSARI	3	3201180012	SITUSARI	1
4	32.01.07.2008	CIPEUCANG	4	3201180013	CIPEUCANG	1
5	32.01.07.2006	JATISARI	5	3201180014	JATISARI	1
6	32.01.07.2005	GANDOANG	6	3201180015	GANDOANG	1
7	32.01.07.2002	MEKARSARI	7	3201180016	MEKARSARI	1
8	32.01.07.2007	CILEUNGSI KIDUL	8	3201180017	CILEUNGSI KIDUL	1
9	32.01.07.2012	CILEUNGSI	9	3201180018	CILEUNGSI	1
10	32.01.07.2011	LIMUSNUNG-GAL	10	3201180019	LIMUSNUNG-GAL	1
11	32.01.07.2001	PASIR ANGIN	11	3201180020	PASIR ANGIN	1
12	32.01.07.2010	CIPENJO	12	3201180021	CIPENJO	1

Catatan :
*) 1. Perkotaan
2. Perdesaan

https://jabar.bps.go.id

DAFTAR DESA/KELURAHAN

PROVINSI : [32] JAWA BARAT
KAB/KOTA : [01] BOGOR
KECAMATAN : [181] KLAPANUNGGAL

Data Kemendagri			MFD 2021 Semester 2			
No	Kode	Nama Desa	No	Kode	Nama Desa	Status*
1	32.01.32.2008	LEUWIKARET	1	3201181001	LEUWIKARET	1
2	32.01.32.2004	LULUT	2	3201181002	LULUT	1
3	32.01.32.2007	BANTAR JATI	3	3201181003	BANTAR JATI	1
4	32.01.32.2003	NAMBO	4	3201181004	NAMBO	1
5	32.01.32.2006	KEMBANG KUNING	5	3201181005	KEMBANG KUNING	1
6	32.01.32.2001	KLAPANUNG-GAL	6	3201181006	KLAPANUNG-GAL	1
7	32.01.32.2009	LIGARMUKTI	7	3201181007	LIGARMUKTI	2
8	32.01.32.2002	BOJONG	8	3201181008	BOJONG	1
9	32.01.32.2005	CIKAHURIPAN	9	3201181009	CIKAHURIPAN	1

Catatan :
*) 1. Perkotaan
2. Perdesaan

https://jabar.bps.go.id

PROVINSI : [32] JAWA BARAT
KAB/KOTA : [01] BOGOR
KECAMATAN : [190] GUNUNG PUTRI

Data Kemendagri			MFD 2021 Semester 2			
No	Kode	Nama Desa	No	Kode	Nama Desa	Status*
1	32.01.02.2010	KARANGGAN	1	3201190001	KARANGGAN	1
2	32.01.02.2004	GUNUNG PUTRI	2	3201190002	GUNUNG PUTRI	1
3	32.01.02.2006	TLAJUNG UDIK	3	3201190003	TLAJUNG UDIK	1
4	32.01.02.2005	BOJONG NANGKA	4	3201190004	BOJONG NANGKA	1
5	32.01.02.2007	CICADAS	5	3201190005	CICADAS	1
6	32.01.02.2001	WANAHERANG	6	3201190006	WANAHERANG	1
7	32.01.02.2008	CIKEAS UDIK	7	3201190007	CIKEAS UDIK	1
8	32.01.02.2009	NAGRAK	8	3201190008	NAGRAK	1
9	32.01.02.2003	CIANGSANA	9	3201190009	CIANGSANA	1
10	32.01.02.2002	BOJONG KULUR	10	3201190010	BOJONG KULUR	1

Catatan :
*) 1. Perkotaan
2. Perdesaan

https://jabar.bps.go.id

DAFTAR DESA/KELURAHAN

PROVINSI : [32] JAWA BARAT
KAB/KOTA : [01] BOGOR
KECAMATAN : [200] CITEUREUP

Data Kemendagri			MFD 2021 Semester 2			
No	Kode	Nama Desa	No	Kode	Nama Desa	Status*
1	32.01.03.2011	TANGKIL	1	3201200001	TANGKIL	2
2	32.01.03.2013	HAMBALANG	2	3201200002	HAMBALANG	2
3	32.01.03.2004	TAJUR	3	3201200003	TAJUR	1
4	32.01.03.2014	PASIR MUKTI	4	3201200004	PASIR MUKTI	1
5	32.01.03.2012	SUKAHATI	5	3201200005	SUKAHATI	1
6	32.01.03.2003	LEUWINUTUG	6	3201200006	LEUWINUTUG	1
7	32.01.03.2005	SANJA	7	3201200007	SANJA	1
8	32.01.03.1007	KARANG ASEM BARAT	8	3201200008	KARANG ASEM BARAT	1
9	32.01.03.2008	KARANG ASEM TIMUR	9	3201200009	KARANG ASEM TIMUR	1
10	32.01.03.2009	TARIKOLOT	10	3201200010	TARIKOLOT	1
11	32.01.03.2010	GUNUNG SARI	11	3201200011	GUNUNG SARI	1
12	32.01.03.2002	CITEUREUP	12	3201200012	CITEUREUP	1
13	32.01.03.1006	PUSPANEGARA	13	3201200013	PUSPANEGARA	1
14	32.01.03.2001	PUSPASARI	14	3201200014	PUSPASARI	1

Catatan :
*) 1. Perkotaan
2. Perdesaan

https://jabar.bps.go.id

PROVINSI : [32] JAWA BARAT
KAB/KOTA : [01] BOGOR
KECAMATAN : [210] CIBINONG

Data Kemendagri			MFD 2021 Semester 2			
No	Kode	Nama Desa	No	Kode	Nama Desa	Status*
1	32.01.01.1002	KARADENAN	1	3201210001	KARADENAN	1
2	32.01.01.1004	NANGGEWER	2	3201210002	NANGGEWER	1
3	32.01.01.1005	NANGGEWER MEKAR	3	3201210003	NANGGEWER MEKAR	1
4	32.01.01.1006	CIBINONG	4	3201210004	CIBINONG	1
5	32.01.01.1007	PAKANSARI	5	3201210005	PAKANSARI	1
6	32.01.01.1009	SUKAHATI	6	3201210006	SUKAHATI	1
7	32.01.01.1008	TENGAH	7	3201210007	TENGAH	1
8	32.01.01.1001	PONDOK RAJEG	8	3201210008	PONDOK RAJEG	1
9	32.01.01.1003	HARAPAN JAYA	9	3201210009	HARAPAN JAYA	1
10	32.01.01.1012	PABUARAN	10	3201210010	PABUARAN	1
11	32.01.01.1011	CIRIMEKAR	11	3201210011	CIRIMEKAR	1
12	32.01.01.1010	CIRIUNG	12	3201210012	CIRIUNG	1
13	32.01.01.1013	PABUARAN MEKAR	13	3201210013	PABUARAN MEKAR	1

Catatan :
*) 1. Perkotaan
2. Perdesaan

https://jabar.bps.go.id

DAFTAR DESA/KELURAHAN

PROVINSI : [32] JAWA BARAT
KAB/KOTA : [01] BOGOR
KECAMATAN : [220] BOJONG GEDE

Data Kemendagri			MFD 2021 Semester 2			
No	Kode	Nama Desa	No	Kode	Nama Desa	Status*
1	32.01.13.2002	CIMANGGIS	1	3201220002	CIMANGGIS	1
2	32.01.13.2006	WARINGIN JAYA	2	3201220003	WARINGIN JAYA	1
3	32.01.13.2005	KEDUNG WARINGIN	3	3201220004	KEDUNG WARINGIN	1
4	32.01.13.2009	BOJONG GEDE	4	3201220005	BOJONG GEDE	1
5	32.01.13.2003	SUSUKAN	5	3201220011	SUSUKAN	1
6	32.01.13.2001	BOJONG BARU	6	3201220012	BOJONG BARU	1
7	32.01.13.2008	RAWA PAN-JANG	7	3201220013	RAWA PAN-JANG	1
8	32.01.13.1007	PABUARAN	8	3201220014	PABUARAN	1
9	32.01.13.2004	RAGAJAYA	9	3201220015	RAGAJAYA	1

https://jabar.bps.go.id

Catatan :
*) 1. Perkotaan
2. Perdesaan

PROVINSI : [32] JAWA BARAT
KAB/KOTA : [01] BOGOR
KECAMATAN : [221] TAJUR HALANG

Data Kemendagri			MFD 2021 Semester 2			
No	Kode	Nama Desa	No	Kode	Nama Desa	Status*
1	32.01.37.2006	TONJONG	1	3201221001	TONJONG	1
2	32.01.37.2001	TAJUR HALANG	2	3201221002	TAJUR HALANG	1
3	32.01.37.2005	SUKMAJAYA	3	3201221003	SUKMAJAYA	1
4	32.01.37.2004	NANGGERANG	4	3201221004	NANGGERANG	1
5	32.01.37.2003	SASAK PANJANG	5	3201221005	SASAK PANJANG	1
6	32.01.37.2007	KALISUREN	6	3201221006	KALISUREN	1
7	32.01.37.2002	CITAYAM	7	3201221007	CITAYAM	1

Catatan :
*) 1. Perkotaan
2. Perdesaan

https://jabar.bps.go.id

DAFTAR DESA/KELURAHAN

PROVINSI : [32] JAWA BARAT
KAB/KOTA : [01] BOGOR
KECAMATAN : [230] KEMANG

Data Kemendagri			MFD 2021 Semester 2			
No	Kode	Nama Desa	No	Kode	Nama Desa	Status*
1	32.01.12.2005	SEMPLAK BARAT	1	3201230006	SEMPLAK BARAT	1
2	32.01.12.1006	ATANG SEN-JAYA	2	3201230007	ATANG SEN-JAYA	1
3	32.01.12.2002	PARAKAN JAYA	3	3201230008	PARAKAN JAYA	1
4	32.01.12.2001	BOJONG	4	3201230009	BOJONG	1
5	32.01.12.2003	KEMANG	5	3201230010	KEMANG	1
6	32.01.12.2004	PABUARAN	6	3201230011	PABUARAN	1
7	32.01.12.2009	TEGAL	7	3201230013	TEGAL	1
8	32.01.12.2008	PONDOK UDIK	8	3201230014	PONDOK UDIK	1
9	32.01.12.2007	JAMPANG	9	3201230015	JAMPANG	1

Catatan :
*) 1. Perkotaan
2. Perdesaan

https://jabar.bps.go.id

PROVINSI : [32] JAWA BARAT
KAB/KOTA : [01] BOGOR
KECAMATAN : [231] RANCABUNGUR

Data Kemendagri			MFD 2021 Semester 2			
No	Kode	Nama Desa	No	Kode	Nama Desa	Status*
1	32.01.34.2001	MEKARSARI	1	3201230006	MEKARSARI	1
2	32.01.34.2002	RANCABUNGUR	2	3201230007	RANCABUNGUR	1
3	32.01.34.2003	PASIR GAOK	3	3201230008	PASIR GAOK	1
4	32.01.34.2004	BANTARJAYA	4	3201230009	BANTARJAYA	1
5	32.01. 34.2005	BANTARSARI	5	3201230010	BANTARSARI	1
6	32.01.34.2006	CANDALI	6	3201230011	CANDALI	2
7	32.01.34.2007	CIMULANG	7	3201230013	CIMULANG	1

Catatan :
*) 1. Perkotaan
2. Perdesaan

https://jabar.bps.go.id

DAFTAR DESA/KELURAHAN

PROVINSI : [32] JAWA BARAT
KAB/KOTA : [01] BOGOR
KECAMATAN : [240] PARUNG

Data Kemendagri			MFD 2021 Semester 2			
No	Kode	Nama Desa	No	Kode	Nama Desa	Status*
1	32.01.10.2002	IWUL	1	3201240009	IWUL	2
2	32.01.10.2009	JABON MEKAR	2	3201240010	JABON MEKAR	1
3	32.01.10.2006	PAMAGER SARI	3	3201240011	PAMAGER SARI	1
4	32.01.10.2001	PARUNG	4	3201240012	PARUNG	1
5	32.01.10.2004	WARU	5	3201240013	WARU	1
6	32.01.10.2007	WARUJAYA	6	3201240014	WARUJAYA	1
7	32.01.10.2003	BOJONG SEMPU	7	3201240015	BOJONG SEMPU	1
8	32.01.10.2008	BOJONG INDAH	8	3201240016	BOJONG INDAH	1
9	32.01.10.2005	COGREG	9	3201240017	COGREG	1

Catatan :
*) 1. Perkotaan
2. Perdesaan

https://jabar.bps.go.id

PROVINSI : [32] JAWA BARAT
KAB/KOTA : [01] BOGOR
KECAMATAN : [241] CISEENG

Data Kemendagri			MFD 2021 Semester 2			
No	Kode	Nama Desa	No	Kode	Nama Desa	Status*
1	32.01.33.2006	KARIHKIL	1	3201241001	KARIHKIL	1
2	32.01.33.2005	CIBEUTEUNG UDIK	2	3201241002	CIBEUTEUNG UDIK	1
3	32.01.33.2007	BABAKAN	3	3201241003	BABAKAN	1
4	32.01.33.2001	PUTAT NUTUG	4	3201241004	PUTAT NUTUG	1
5	32.01.33.2009	CIBEUTEUNG MUARA	5	3201241005	CIBEUTEUNG MUARA	2
6	32.01.33.2004	CIBENTANG	6	3201241006	CIBENTANG	1
7	32.01.33.2003	PARIGI MEKAR	7	3201241007	PARIGI MEKAR	1
8	32.01.33.2002	CISEENG	8	3201241008	CISEENG	1
9	32.01.33.2008	CIHOWE	9	3201241009	CIHOWE	2
10	32.01.33.2010	KURIPAN	10	3201241010	KURIPAN	2

Catatan :
*) 1. Perkotaan
2. Perdesaan

https://jabar.bps.go.id

DAFTAR DESA/KELURAHAN

PROVINSI : [32] JAWA BARAT
KAB/KOTA : [01] BOGOR
KECAMATAN : [250] GUNUNG SINDUR

Data Kemendagri			MFD 2021 Semester 2			
No	Kode	Nama Desa	No	Kode	Nama Desa	Status*
1	32.01.11.2006	JAMPANG	1	3201250001	JAMPANG	2
2	32.01.11.2007	CIBADUNG	2	3201250002	CIBADUNG	1
3	32.01.11.2008	CIBINONG	3	3201250003	CIBINONG	1
4	32.01.11.2001	CIDOKOM	4	3201250004	CIDOKOM	1
5	32.01.11.2002	PADURENAN	5	3201250005	PADURENAN	1
6	32.01.11.2004	CURUG	6	3201250006	CURUG	1
7	32.01.11.2009	RAWAKALONG	7	3201250007	RAWAKALONG	1
8	32.01.11.2003	PENGASINAN	8	3201250008	PENGASINAN	1
9	32.01.11.2005	GUNUNG SINDUR	9	3201250009	GUNUNG SINDUR	1
10	32.01.11.2010	PABUARAN	10	3201250010	PABUARAN	1

Catatan :
*) 1. Perkotaan
2. Perdesaan

https://jabar.bps.go.id

PROVINSI : [32] JAWA BARAT
KAB/KOTA : [01] BOGOR
KECAMATAN : [260] RUMPIN

Data Kemendagri			MFD 2021 Semester 2			
No	Kode	Nama Desa	No	Kode	Nama Desa	Status*
1	32.01.18.2002	LEUWIBATU	1	3201260001	LEUWIBATU	2
2	32.01.18.2003	CIDOKOM	2	3201260002	CIDOKOM	2
3	32.01.18.2004	GOBANG	3	3201260003	GOBANG	2
4	32.01.18.2006	RABAK	4	3201260004	RABAK	1
5	32.01.18.2005	CIBODAS	5	3201260005	CIBODAS	2
6	32.01.18.2007	KAMPUNG SAWAH	6	3201260006	KAMPUNG SAWAH	1
7	32.01.18.2001	RUMPIN	7	3201260007	RUMPIN	2
8	32.01.18.2008	CIPINANG	8	3201260008	CIPINANG	2
9	32.01.18.2009	SUKASARI	9	3201260009	SUKASARI	2
10	32.01.18.2011	KERTAJAYA	10	3201260010	KERTAJAYA	2
11	32.01.18.2010	TAMANSARI	11	3201260011	TAMANSARI	1
12	32.01.18.2012	SUKAMULYA	12	3201260012	SUKAMULYA	1
13	32.01.18.2013	MEKARSARI	13	3201260013	MEKARSARI	1
14	32.01.18.2014	MEKARJAYA	14	3201260014	MEKARJAYA	2

Catatan :
*) 1. Perkotaan
2. Perdesaan

https://jabar.bps.go.id

DAFTAR DESA/KELURAHAN

PROVINSI : [32] JAWA BARAT
KAB/KOTA : [01] BOGOR
KECAMATAN : [270] CIGUDEG

Data Kemendagri			MFD 2021 Semester 2			
No	Kode	Nama Desa	No	Kode	Nama Desa	Status*
1	32.01.22.2011	SUKARAKSA	1	3201270001	SUKARAKSA	2
2	32.01.22.2001	SUKAMAJU	2	3201270002	SUKAMAJU	1
3	32.01.22.2002	CIGUDEG	3	3201270003	CIGUDEG	1
‘4	32.01.22.2004	BANYURESMI	4	3201270004	BANYURESMI	2
5	32.01.22.2010	WARGAJAYA	5	3201270005	WARGAJAYA	1
6	32.01.22.2003	BUNAR	6	3201270006	BUNAR	2
7	32.01.22.2014	MEKARJAYA	7	3201270007	MEKARJAYA	2
8	32.01.22.2005	CINTAMANIK	8	3201270008	CINTAMANIK	2
9	32.01.22.2012	BANYUWANGI	9	3201270009	BANYUWANGI	2
10	32.01.22.2013	BANYUASIH	10	3201270010	BANYUASIH	2
11	32.01.22.2015	TEGALLEGA	11	3201270011	TEGALLEGA	2
12	32.01.22.2009	BATUJAJAR	12	3201270012	BATUJAJAR	2
13	32.01.22.2008	RENGASJAJAR	13	3201270013	RENGASJAJAR	2
14	32.01.22.2007	BANGUNJAYA	14	3201270021	BANGUNJAYA	2
15	32.01.22.2006	ARGAPURA	15	3201270022	ARGAPURA	2

Catatan :
*) 1. Perkotaan
2. Perdesaan

https://jabar.bps.go.id

PROVINSI : [32] JAWA BARAT
KAB/KOTA : [01] BOGOR
KECAMATAN : [271] SUKAJAYA

Data Kemendagri			MFD 2021 Semester 2			
No	Kode	Nama Desa	No	Kode	Nama Desa	Status*
1	32.01.35.2001	CISARUA	1	3201271001	CISARUA	2
2	32.01.35.2002	KIARASARI	2	3201271002	KIARASARI	2
3	32.01.35.2006	KIARAPANDAK	3	3201271003	KIARAPANDAK	2
4	32.01.35.2007	HARKATJAYA	4	3201271004	HARKATJAYA	2
5	32.01.35.2003	SUKAJAYA	5	3201271005	SUKAJAYA	2
6	32.01.35.2004	SIPAYUNG	6	3201271006	SIPAYUNG	2
7	32.01.35.2008	SUKAMULIH	7	3201271007	SUKAMULIH	2
8	32.01.35.2009	PASIR MADANG	8	3201271008	PASIR MADANG	2
9	32.01.35.2005	CILEUKSA	9	3201271009	CILEUKSA	2
10	32.01.35.2010	URUG	10	3201271010	URUG	2
11	32.01.35.2011	JAYARAHARJA	11	3201271011	JAYARAHARJA	2

Catatan :
*) 1. Perkotaan
2. Perdesaan

https://jabar.bps.go.id

DAFTAR DESA/KELURAHAN

PROVINSI : [32] JAWA BARAT
KAB/KOTA : [01] BOGOR
KECAMATAN : [280] JASINGA

Data Kemendagri			MFD 2021 Semester 2			
No	Kode	Nama Desa	No	Kode	Nama Desa	Status*
1	32.01.19.2002	PANGRADIN	1	3201280003	PANGRADIN	2
2	32.01.19.2003	KALONG-SAWAH	2	3201280004	KALONG-SAWAH	1
3	32.01.19.2004	SIPAK	3	3201280005	SIPAK	1
‘4	32.01.19.2012	PAMAGERSARI	4	3201280006	PAMAGERSARI	1
5	32.01.19.2013	JUGALAJAYA	5	3201280007	JUGALAJAYA	2
6	32.01.19.2001	CURUG	6	3201280008	CURUG	2
7	32.01.19.2014	TEGALWANGI	7	3201280009	TEGALWANGI	2
8	32.01.19.2006	KOLEANG	8	3201280010	KOLEANG	2
9	32.01.19.2005	JASINGA	9	3201280011	JASINGA	1
10	32.01.19.2008	SETU	10	3201280012	SETU	1
11	32.01.19.2007	CIKOPOMAYAK	11	3201280013	CIKOPOMAYAK	2
12	32.01.19.2015	NEGLASARI	12	3201280014	NEGLASARI	2
13	32.01.19.2010	BAGOANG	13	3201280015	BAGOANG	2
14	32.01.19.2009	BARENGKOK	14	3201280016	BARENGKOK	2
15	32.01.19.2011	PANGAUR	15	3201280017	PANGAUR	2
16	32.01.19.2016	WIRAJAYA	16	3201280018	WIRAJAYA	2

Catatan :
*) 1. Perkotaan
2. Perdesaan

https://jabar.bps.go.id

PROVINSI : [32] JAWA BARAT
KAB/KOTA : [01] BOGOR
KECAMATAN : [290] TENJO

Data Kemendagri			MFD 2021 Semester 2			
No	Kode	Nama Desa	No	Kode	Nama Desa	Status*
1	32.01.23.2002	CIOMAS	1	3201290001	CIOMAS	2
2	32.01.23.2001	TAPOK	2	3201290002	TAPOK	2
3	32.01.23.2003	BATOK	3	3201290003	BATOK	2
4	32.01.23.2004	BABAKAN	4	3201290004	BABAKAN	2
5	32.01.23.2009	BOJONG	5	3201290005	BOJONG	2
6	32.01.23.2007	SINGABRAJA	6	3201290006	SINGABRAJA	2
7	32.01.23.2005	TENJO	7	3201290007	TENJO	1
8	32.01.23.2006	CILAKU	8	3201290008	CILAKU	2
9	32.01.23.2008	SINGABANGSA	9	3201290009	SINGABANGSA	2

Catatan :
*) 1. Perkotaan
2. Perdesaan

https://jabar.bps.go.id

DAFTAR DESA/KELURAHAN

PROVINSI : [32] JAWA BARAT
KAB/KOTA : [01] BOGOR
KECAMATAN : [300] PARUNG PANJANG

Data Kemendagri			MFD 2021 Semester 2			
No	Kode	Nama Desa	No	Kode	Nama Desa	Status*
1	32.01.20.2001	JAGABAYA	1	3201300001	JAGABAYA	2
2	32.01.20.2002	GOROWONG	2	3201300002	GOROWONG	2
3	32.01.20.2003	DAGO	3	3201300003	DAGO	2
4	32.01.20.2005	CIKUDA	4	3201300004	CIKUDA	2
5	32.01.20.2004	PINGKU	5	3201300005	PINGKU	2
6	32.01.20.2007	LUMPANG	6	3201300006	LUMPANG	1
7	32.01.20.2010	GINTUNG CILEJET	7	3201300007	GINTUNG CILEJET	2
8	32.01.20.2009	JAGABITA	8	3201300008	JAGABITA	2
9	32.01.20.2008	CIBUNAR	9	3201300009	CIBUNAR	1
10	32.01.20.2006	PARUNG PANJANG	10	3201300010	PARUNG PANJANG	1
11	32.01.20.2011	KABASIRAN	11	3201300011	KABASIRAN	1

Catatan :
*) 1. Perkotaan
2. Perdesaan

https://jabar.bps.go.id

KABUPATEN SUKABUMI

https://jabar.bps.go.id

https://jabar.bps.go.id

PROVINSI : [32] JAWA BARAT
KAB/KOTA : [02] SUKABUMI

Data Kemendagri			MFD 2021 Semester 2		
No	Kode	Nama Kecamatan	No	Kode	Nama Kecamatan
1	32.02.22	CIEMAS	1	3202010	CIEMAS
2	32.02.26	CIRACAP	2	3202020	CIRACAP
3	32.02.20	WALURAN	3	3202021	WALURAN
4	32.02.24	SURADE	4	3202030	SURADE
5	32.02.25	CIBITUNG	5	3202031	CIBITUNG
6	32.02.21	JAMPANGKULON	6	3202040	JAMPANG KULON
7	32.02.46	CIMANGGU	7	3202041	CIMANGGU
8	32.02.23	KALIBUNDER	8	3202050	KALI BUNDER
9	32.02.45	TEGALBULEUD	9	3202060	TEGAL BULEUD
10	32.02.43	CIDOLOG	10	3202070	CIDOLOG
11	32.02.41	SAGARANTEN	11	3202080	SAGARANTEN
12	32.02.44	CIDADAP	12	3202081	CIDADAP
13	32.02.42	CURUGKEMBAR	13	3202082	CURUGKEMBAR
14	32.02.37	PABUARAN	14	3202090	PABUARAN
15	32.02.07	LENGKONG	15	3202100	LENGKONG
16	32.02.01	PALABUHANRATU	16	3202110	PALABUHANRATU
17	32.02.02	SIMPENAN	17	3202111	SIMPENAN
18	32.02.09	WARUNGKIARA	18	3202120	WARUNG KIARA
19	32.02.04	BANTARGADUNG	19	3202121	BANTARGADUNG
20	32.02.08	JAMPANGTENGAH	20	3202130	JAMPANG TENGAH
21	32.02.38	PURABAYA	21	3202131	PURABAYA
22	32.02.10	CIKEMBAR	22	3202140	CIKEMBAR
23	32.02.39	NYALINDUNG	23	3202150	NYALINDUNG

https://jabar.bps.go.id

DAFTAR KECAMATAN

PROVINSI : [32] JAWA BARAT
KAB/KOTA : [02] SUKABUMI

Data Kemendagri			MFD 2021 Semester 2		
No	Kode	Nama Kecamatan	No	Kode	Nama Kecamatan
24	32.02.40	GEGERBITUNG	24	3202160	GEGER BITUNG
25	32.02.33	SUKARAJA	25	3202170	SUKARAJA
26	32.02.34	KEBONPEDES	26	3202171	KEBONPEDES
27	32.02.35	CIREUNGHAS	27	3202172	CIREUNGHAS
28	32.02.36	SUKALARANG	28	3202173	SUKALARANG
29	32.02.32	SUKABUMI	29	3202180	SUKABUMI
30	32.02.30	KADUDAMPIT	30	3202190	KADUDAMPIT
31	32.02.29	CISAAT	31	3202200	CISAAT
32	32.02.27	GUNUNGGURUH	32	3202201	GUNUNG GURUH
33	32.02.11	CIBADAK	33	3202210	CIBADAK
34	32.02.28	CICANTAYAN	34	3202211	CICANTAYAN
35	32.02.31	CARINGIN	35	3202212	CARINGIN
36	32.02.12	NAGRAK	36	3202220	NAGRAK
37	32.02.47	CIAMBAR	37	3202221	CIAMBAR
38	32.02.16	CICURUG	38	3202230	CICURUG
39	32.02.17	CIDAHU	39	3202240	CIDAHU
40	32.02.15	PARAKANSALAK	40	3202250	PARAKAN SALAK
41	32.02.13	PARUNGKUDA	41	3202260	PARUNG KUDA
42	32.02.14	BOJONGGENTENG	42	3202261	BOJONG GENTENG
43	32.02.18	KALAPANUNGGAL	43	3202270	KALAPA NUNGGAL
44	32.02.06	CIKIDANG	44	3202280	CIKIDANG
45	32.02.05	CISOLOK	45	3202290	CISOLOK
46	32.02.03	CIKAKAK	46	3202291	CIKAKAK
47	32.02.19	KABANDUNGAN	47	3202300	KABANDUNGAN

https://jabar.bps.go.id

JUMLAH DESA/KELURAHAN PER KECAMATAN

PROVINSI : [32] JAWA BARAT
KAB/KOTA : [02] SUKABUMI

Data Kemendagri				MFD 2021 Semester 2			
No	Kode	Nama Kecamatan	Jml Desa	No	Kode	Nama Kecamatan	Jml Desa
1	32.02.22	CIEMAS	9	1	3202010	CIEMAS	9
2	32.02.26	CIRACAP	8	2	3202020	CIRACAP	8
3	32.02.20	WALURAN	6	3	3202021	WALURAN	6
4	32.02.24	SURADE	12	4	3202030	SURADE	12
5	32.02.25	CIBITUNG	6	5	3202031	CIBITUNG	6
6	32.02.21	JAMPANGKULON	11	6	3202040	JAMPANG KULON	11
7	32.02.46	CIMANGGU	6	7	3202041	CIMANGGU	6
8	32.02.23	KALIBUNDER	7	8	3202050	KALI BUNDER	7
9	32.02.45	TEGALBULEUD	8	9	3202060	TEGAL BULEUD	8
10	32.02.43	CIDOLOG	5	10	3202070	CIDOLOG	5
11	32.02.41	SAGARANTEN	12	11	3202080	SAGARANTEN	12
12	32.02.44	CIDADAP	6	12	3202081	CIDADAP	6
13	32.02.42	CURUGKEMBAR	7	13	3202082	CURUGKEMBAR	7
14	32.02.37	PABUARAN	7	14	3202090	PABUARAN	7
15	32.02.07	LENGKONG	5	15	3202100	LENGKONG	5
16	32.02.01	PALABUHANRATU	10	16	3202110	PALABUHANRATU	10
17	32.02.02	SIMPENAN	7	17	3202111	SIMPENAN	7
18	32.02.09	WARUNGKIARA	12	18	3202120	WARUNG KIARA	12
19	32.02.04	BANTARGADUNG	7	19	3202121	BANTARGADUNG	7
20	32.02.08	JAMPANGTENG-AH	11	20	3202130	JAMPANG TENG-AH	11
21	32.02.38	PURABAYA	7	21	3202131	PURABAYA	7
22	32.02.10	CIKEMBAR	10	22	3202140	CIKEMBAR	10
23	32.02.39	NYALINDUNG	10	23	3202150	NYALINDUNG	10
24	32.02.40	GEGERBITUNG	7	24	3202160	GEGER BITUNG	7

https://jabar.bps.go.id

JUMLAH DESA/KELURAHAN PER KECAMATAN

PROVINSI : [32] JAWA BARAT
KAB/KOTA : [02] SUKABUMI

Data Kemendagri				MFD 2021 Semester 2			
No	Kode	Nama Kecamatan	Jml Desa	No	Kode	Nama Kecamatan	Jml Desa
25	32.02.33	SUKARAJA	9	25	3202170	SUKARAJA	9
26	32.02.34	KEBONPEDES	5	26	3202171	KEBONPEDES	5
27	32.02.35	CIREUNGHAS	5	27	3202172	CIREUNGHAS	5
28	32.02.36	SUKALARANG	6	28	3202173	SUKALARANG	6
29	32.02.32	SUKABUMI	6	29	3202180	SUKABUMI	6
30	32.02.30	KADUDAMPIT	9	30	3202190	KADUDAMPIT	9
31	32.02.29	CISAAT	13	31	3202200	CISAAT	13
32	32.02.27	GUNUNGGURUH	7	32	3202201	GUNUNGGURUH	7
33	32.02.11	CIBADAK	10	33	3202210	CIBADAK	10
34	32.02.28	CICANTAYAN	8	34	3202211	CICANTAYAN	8
35	32.02.31	CARINGIN	9	35	3202212	CARINGIN	9
36	32.02.12	NAGRAK	10	36	3202220	NAGRAK	10
37	32.02.47	CIAMBAR	6	37	3202221	CIAMBAR	6
38	32.02.16	CICURUG	13	38	3202230	CICURUG	13
39	32.02.17	CIDAHU	8	39	3202240	CIDAHU	8
40	32.02.15	PARAKANSALAK	6	40	3202250	PARAKAN SALAK	6
41	32.02.13	PARUNGKUDA	8	41	3202260	PARUNG KUDA	8
42	32.02.14	BOJONGGEN-TENG	5	42	3202261	BOJONG GEN-TENG	5
43	32.02.18	KALAPANUNG-GAL	7	43	3202270	KALAPA NUNG-GAL	7
44	32.02.06	CIKIDANG	12	44	3202280	CIKIDANG	12
45	32.02.05	CISOLOK	13	45	3202290	CISOLOK	13
46	32.02.03	CIKAKAK	9	46	3202291	CIKAKAK	9
47	32.02.19	KABANDUNGAN	6	47	3202300	KABANDUNGAN	6

https://jabar.bps.go.id

PROVINSI : [32] JAWA BARAT
KAB/KOTA : [02] SUKABUMI
KECAMATAN : [010] CIEMAS

Data Kemendagri			MFD 2021 Semester 2			
No	Kode	Nama Desa	No	Kode	Nama Desa	Status*
1	32.02.22.2002	CIBENDA	1	3202010001	CIBENDA	2
2	32.02.22.2003	CIWARU	2	3202010002	CIWARU	2
3	32.02.22.2006	TAMANJAYA	3	3202010003	TAMANJAYA	2
4	32.02.22.2004	MEKARJAYA	4	3202010004	MEKARJAYA	2
5	32.02.22.2001	CIEMAS	5	3202010005	CIEMAS	2
6	32.02.22.2005	GIRIMUKTI	6	3202010006	GIRIMUKTI	2
7	32.02.22.2007	MANDRAJAYA	7	3202010007	MANDRAJAYA	2
8	32.02.22.2009	MEKARSAKTI	8	3202010008	MEKARSAKTI	2
9	32.02.22.2008	SIDAMULYA	9	3202010009	SIDAMULYA	2

Catatan :
*) 1. Perkotaan
2. Perdesaan

https://jabar.bps.go.id

DAFTAR DESA/KELURAHAN

PROVINSI : [32] JAWA BARAT
KAB/KOTA : [02] SUKABUMI
KECAMATAN : [020] CIRACAP

Data Kemendagri			MFD 2021 Semester 2			
No	Kode	Nama Desa	No	Kode	Nama Desa	Status*
1	32.02.26.2003	GUNUNGBATU	1	3202020001	GUNUNGBATU	2
2	32.02.26.2002	CIKANGKUNG	2	3202020002	CIKANGKUNG	2
3	32.02.26.2004	PURWASEDAR	3	3202020003	PURWASEDAR	2
4	32.02.26.2001	CIRACAP	4	3202020004	CIRACAP	2
5	32.02.26.2005	PASIRPANJANG	5	3202020005	PASIRPANJANG	2
6	32.02.26.2006	MEKARSARI	6	3202020006	MEKARSARI	2
7	32.02.26.2008	PANGUMBA-HAN	7	3202020007	PANGUMBA-HAN	2
8	32.02.26.2007	UJUNG GEN-TENG	8	3202020008	UJUNG GEN-TENG	2

Catatan :
*) 1. Perkotaan
2. Perdesaan

https://jabar.bps.go.id

PROVINSI : [32] JAWA BARAT
KAB/KOTA : [02] SUKABUMI
KECAMATAN : [021] WALURAN

Data Kemendagri			MFD 2021 Semester 2			
No	Kode	Nama Desa	No	Kode	Nama Desa	Status*
1	32.02.20.2003	CARINGIN NUNGGAL	1	3202021001	CARINGIN NUNGGAL	2
2	32.02.20.2001	WALURAN	2	3202021002	WALURAN	2
3	32.02.20.2002	SUKAMUKTI	3	3202021003	SUKAMUKTI	2
4	32.02.20.2004	MEKAR MUKTI	4	3202021004	MEKAR MUKTI	2
5	32.02.20.2006	WALURAN MANDIRI	5	3202021005	WALURAN MANDIRI	2
6	32.02.20.2005	MANGUNJAYA	6	3202021006	MANGUNJAYA	2

Catatan :
*) 1. Perkotaan
2. Perdesaan

https://jabar.bps.go.id

DAFTAR DESA/KELURAHAN

PROVINSI : [32] JAWA BARAT
KAB/KOTA : [02] SUKABUMI
KECAMATAN : [030] SURADE

Data Kemendagri			MFD 2021 Semester 2			
No	Kode	Nama Desa	No	Kode	Nama Desa	Status*
1	32.02.24.2009	PASIRIPIS	1	3202030001	PASIRIPIS	2
2	32.02.24.2010	BUNIWANGI	2	3202030002	BUNIWANGI	2
3	32.02.24.2008	CIPEUNDEUY	3	3202030003	CIPEUNDEUY	2
4	32.02.24.2007	GUNUNG SUNGGING	4	3202030004	GUNUNG SUNGGING	2
5	32.02.24.2002	CITANGLAR	5	3202030011	CITANGLAR	2
6	32.02.24.2001	JAGAMUKTI	6	3202030012	JAGAMUKTI	2
7	32.02.24.1013	SURADE	7	3202030013	SURADE	1
8	32.02.24.2006	KADALEMAN	8	3202030014	KADALEMAN	2
9	32.02.24.2003	WANASARI	9	3202030015	WANASARI	2
10	32.02.24.2005	SIRNASARI	10	3202030016	SIRNASARI	2
11	32.02.24.2011	SUKATANI	11	3202030017	SUKATANI	2
12	32.02.24.2012	KADEMANGAN	12	3202030018	KADEMANGAN	2

Catatan :
*) 1. Perkotaan
2. Perdesaan

https://jabar.bps.go.id

PROVINSI : [32] JAWA BARAT
KAB/KOTA : [02] SUKABUMI
KECAMATAN : [031] CIBITUNG

Data Kemendagri			MFD 2021 Semester 2			
No	Kode	Nama Desa	No	Kode	Nama Desa	Status*
1	32.02.25.2004	CIDAHU	1	3202031001	CIDAHU	2
2	32.02.25.2003	CIBITUNG	2	3202031002	CIBITUNG	2
3	32.02.25.2006	BANYUWANGI	3	3202031003	BANYUWANGI	2
4	32.02.25.2005	CIBODAS	4	3202031004	CIBODAS	2
5	32.02.25.2002	BANYUMURNI	5	3202031005	BANYUMURNI	2
6	32.02.25.2001	TALAGAMURNI	6	3202031006	TALAGAMURNI	2

Catatan :
*) 1. Perkotaan
2. Perdesaan

https://jabar.bps.go.id

DAFTAR DESA/KELURAHAN

PROVINSI : [32] JAWA BARAT
KAB/KOTA : [02] SUKABUMI
KECAMATAN : [040] JAMPANG KULON

Data Kemendagri			MFD 2021 Semester 2			
No	Kode	Nama Desa	No	Kode	Nama Desa	Status*
1	32.02.21.2011	CIPARAY	1	3202040001	CIPARAY	1
2	32.02.21.2002	BOJONG GEN-TENG	2	3202040002	BOJONG GEN-TENG	1
3	32.02.21.2005	BOJONGSARI	3	3202040003	BOJONGSARI	2
4	32.02.21.2008	MEKARJAYA	4	3202040004	MEKARJAYA	2
5	32.02.21.2007	NAGRAKSARI	5	3202040005	NAGRAKSARI	1
6	32.02.21.1001	JAMPANG KULON	6	3202040006	JAMPANG KULON	1
7	32.02.21.2009	TANJUNG	7	3202040007	TANJUNG	2
8	32.02.21.2013	PADAJAYA	8	3202040008	PADAJAYA	2
9	32.02.21.2003	CIKARANG	9	3202040013	CIKARANG	2
10	32.02.21.2014	KARANG-ANYAR	10	3202040014	KARANG-ANYAR	2
11	32.02.21.2016	CIKARANG-GEUSAN	11	3202040015	CIKARANG-GEUSAN	2

Catatan :
*) 1. Perkotaan
2. Perdesaan

https://jabar.bps.go.id

PROVINSI : [32] JAWA BARAT
KAB/KOTA : [02] SUKABUMI
KECAMATAN : [041] CIMANGGU

Data Kemendagri			MFD 2021 Semester 2			
No	Kode	Nama Desa	No	Kode	Nama Desa	Status*
1	32.02.46.2005	BOREGAH INDAH	1	3202041001	BOREGAH INDAH	2
2	32.02.46.2001	CIMANGGU	2	3202041002	CIMANGGU	2
3	32.02.46.2002	SUKAMAJU	3	3202041003	SUKAMAJU	2
4	32.02.46.2003	SUKAJADI	4	3202041004	SUKAJADI	2
5	32.02.46.2004	KARANGME-KAR	5	3202041005	KARANGME-KAR	2
6	32.02.46.2006	SUKAMANAH	6	3202041006	SUKAMANAH	2

Catatan :
*) 1. Perkotaan
2. Perdesaan

https://jabar.bps.go.id

DAFTAR DESA/KELURAHAN

PROVINSI : [32] JAWA BARAT
KAB/KOTA : [02] SUKABUMI
KECAMATAN : [050] KALIBUNDER

Data Kemendagri			MFD 2021 Semester 2			
No	Kode	Nama Desa	No	Kode	Nama Desa	Status*
1	32.02.23.2003	CIMAHPAR	1	3202050001	CIMAHPAR	2
2	32.02.23.2004	SEKARSARI	2	3202050002	SEKARSARI	2
3	32.02.23.2001	KALIBUNDER	3	3202050003	KALIBUNDER	2
4	32.02.23.2005	SUKALUYU	4	3202050004	SUKALUYU	1
5	32.02.23.2002	BOJONG	5	3202050005	BOJONG	2
6	32.02.23.2006	BALEKAM-BANG	6	3202050006	BALEKAM-BANG	2
7	32.02.23.2007	MEKARWANGI	7	3202050007	MEKARWANGI	2

Catatan :
*) 1. Perkotaan
2. Perdesaan

https://jabar.bps.go.id

PROVINSI : [32] JAWA BARAT
KAB/KOTA : [02] SUKABUMI
KECAMATAN : [060] TEGAL BULEUD

Data Kemendagri			MFD 2021 Semester 2			
No	Kode	Nama Desa	No	Kode	Nama Desa	Status*
1	32.02.45.2003	SUMBERJAYA	1	3202060001	SUMBERJAYA	2
2	32.02.45.2007	BUNIASIH	2	3202060002	BUNIASIH	2
3	32.02.45.2001	TEGALBULEUD	3	3202060003	TEGALBULEUD	2
4	32.02.45.2004	CALINGCING	4	3202060004	CALINGCING	2
5	32.02.45.2006	RAMBAY	5	3202060005	RAMBAY	2
6	32.02.45.2005	NANGELA	6	3202060006	NANGELA	2
7	32.02.45.2002	BANGBAYANG	7	3202060007	BANGBAYANG	2
8	32.02.45.2008	SIRNAMEKAR	8	3202060008	SIRNAMEKAR	2

Catatan :
*) 1. Perkotaan
2. Perdesaan

https://jabar.bps.go.id

DAFTAR DESA/KELURAHAN

PROVINSI : [32] JAWA BARAT
KAB/KOTA : [02] SUKABUMI
KECAMATAN : [070] CIDOLOG

Data Kemendagri			MFD 2021 Semester 2			
No	Kode	Nama Desa	No	Kode	Nama Desa	Status*
1	32.02.43.2001	CIDOLOG	1	3202070001	CIDOLOG	2
2	32.02.43.2005	MEKARJAYA	2	3202070002	MEKARJAYA	2
3	32.02.43.2003	CIKARANG	3	3202070003	CIKARANG	2
4	32.02.43.2002	CIPAMINGKIS	4	3202070004	CIPAMINGKIS	2
5	32.02.43.2004	TEGALLEGA	5	3202070005	TEGALLEGA	2

Catatan :
*) 1. Perkotaan
2. Perdesaan

https://jabar.bps.go.id

PROVINSI : [32] JAWA BARAT
KAB/KOTA : [02] SUKABUMI
KECAMATAN : [080] SAGARANTEN

Data Kemendagri			MFD 2021 Semester 2			
No	Kode	Nama Desa	No	Kode	Nama Desa	Status*
1	32.02.41.2009	SINAR BEN-TANG	1	3202080005	SINAR BEN-TANG	2
2	32.02.41.2008	GUNUNG BENTANG	2	3202080006	GUNUNG BENTANG	2
3	32.02.41.2004	PASANGGRA-HAN	3	3202080007	PASANGGRA-HAN	1
4	32.02.41.2002	CURUGLUHUR	4	3202080008	CURUGLUHUR	2
5	32.02.41.2005	DATARNANG-KA	5	3202080009	DATARNANG-KA	2
6	32.02.41.2001	SAGARANTEN	6	3202080010	SAGARANTEN	1
7	32.02.41.2011	MARGALUYU	7	3202080011	MARGALUYU	2
8	32.02.41.2010	CIBITUNG	8	3202080012	CIBITUNG	2
9	32.02.41.2007	HEGARMANAH	9	3202080017	HEGARMANAH	2
10	32.02.41.2003	CIBAREGBEG	10	3202080018	CIBAREGBEG	2
11	32.02.41.2006	PUNCAK-MANGGIS	11	3202080019	PUNCAK-MANGGIS	2
12	32.02.41.2012	MEKARSARI	12	3202080020	MEKARSARI	2

Catatan :
*) 1. Perkotaan
2. Perdesaan

https://jabar.bps.go.id

DAFTAR DESA/KELURAHAN

PROVINSI : [32] JAWA BARAT
KAB/KOTA : [02] SUKABUMI
KECAMATAN : [081] CIDADAP

Data Kemendagri			MFD 2021 Semester 2			
No	Kode	Nama Desa	No	Kode	Nama Desa	Status*
1	32.02.44.2004	HEGARMULYA	1	3202081001	HEGARMULYA	2
2	32.02.44.2002	CIDADAP	2	3202081002	CIDADAP	2
3	32.02.44.2001	PADASENANG	3	3202081003	PADASENANG	2
4	32.02.44.2003	BANJARSARI	4	3202081004	BANJARSARI	2
5	32.02.44.2005	TENJOLAUT	5	3202081005	TENJOLAUT	2
6	32.02.44.2006	MEKARTANI	6	3202081006	MEKARTANI	2

Catatan :
*) 1. Perkotaan
2. Perdesaan

https://jabar.bps.go.id

PROVINSI : [32] JAWA BARAT
KAB/KOTA : [02] SUKABUMI
KECAMATAN : [082] CURUGKEMBAR

Data Kemendagri			MFD 2021 Semester 2			
No	Kode	Nama Desa	No	Kode	Nama Desa	Status*
1	32.02.42.2002	CIMENTENG	1	3202082001	CIMENTENG	2
2	32.02.42.2001	CURUGKEM-BAR	2	3202082002	CURUGKEM-BAR	2
3	32.02.42.2003	TANJUNGSARI	3	3202082003	TANJUNGSARI	2
4	32.02.42.2004	SINDANGRAJA	4	3202082004	SINDANGRAJA	2
5	32.02.42.2005	MEKARTAN-JUNG	5	3202082005	MEKARTAN-JUNG	2
6	32.02.42.2007	BOJONG TUGU	6	3202082006	BOJONG TUGU	2
7	32.02.42.2006	NAGRAKJAYA	7	3202082007	NAGRAKJAYA	2

Catatan :
*) 1. Perkotaan
2. Perdesaan

https://jabar.bps.go.id

DAFTAR DESA/KELURAHAN

PROVINSI : [32] JAWA BARAT
KAB/KOTA : [02] SUKABUMI
KECAMATAN : [090] PABUARAN

Data Kemendagri			MFD 2021 Semester 2			
No	Kode	Nama Desa	No	Kode	Nama Desa	Status*
1	32.02.37.2005	SUKAJAYA	1	3202090001	SUKAJAYA	2
2	32.02.37.2002	CIWALAT	2	3202090002	CIWALAT	2
3	32.02.37.2001	PABUARAN	3	3202090003	PABUARAN	2
4	32.02.37.2006	CIBADAK	4	3202090004	CIBADAK	2
5	32.02.37.2003	SIRNASARI	5	3202090005	SIRNASARI	2
6	32.02.37.2004	BANTARSARI	6	3202090006	BANTARSARI	2
7	32.02.37.2007	LEMBUR-SAWAH	7	3202090007	LEMBUR-SAWAH	2

Catatan :
*) 1. Perkotaan
2. Perdesaan

https://jabar.bps.go.id

PROVINSI : [32] JAWA BARAT
KAB/KOTA : [02] SUKABUMI
KECAMATAN : [100] LENGKONG

Data Kemendagri			MFD 2021 Semester 2			
No	Kode	Nama Desa	No	Kode	Nama Desa	Status*
1	32.02.07.2005	LANGKAPJAYA	1	3202100001	LANGKAPJAYA	2
2	32.02.07.2002	CILANGKAP	2	3202100002	CILANGKAP	2
3	32.02.07.2001	LENGKONG	3	3202100003	LENGKONG	2
4	32.02.07.2003	TEGALLEGA	4	3202100004	TEGALLEGA	2
5	32.02.07.2004	NEGLASARI	5	3202100005	NEGLASARI	2

Catatan :
*) 1. Perkotaan
2. Perdesaan

https://jabar.bps.go.id

DAFTAR DESA/KELURAHAN

PROVINSI : [32] JAWA BARAT
KAB/KOTA : [02] SUKABUMI
KECAMATAN : [110] PALABUHANRATU

Data Kemendagri			MFD 2021 Semester 2			
No	Kode	Nama Desa	No	Kode	Nama Desa	Status*
1	32.02.01.2008	CITARIK	1	3202110005	CITARIK	1
2	32.02.01.1001	PALABUHAN-RATU	2	3202110006	PALABUHAN-RATU	1
3	32.02.01.2003	CITEPUS	3	3202110007	CITEPUS	1
4	32.02.01.2005	CIBODAS	4	3202110008	CIBODAS	2
5	32.02.01.2004	BUNIWANGI	5	3202110009	BUNIWANGI	2
6	32.02.01.2007	CIKADU	6	3202110010	CIKADU	2
7	32.02.01.2006	PASIRSUREN	7	3202110011	PASIRSUREN	2
8	32.02.01.2002	TONJONG	8	3202110012	TONJONG	1
9	32.02.01.2010	JAYANTI	9	3202110013	JAYANTI	1
10	32.02.01.2009	CIMANGGU	10	3202110014	CIMANGGU	2

Catatan :
*) 1. Perkotaan
2. Perdesaan

https://jabar.bps.go.id

PROVINSI : [32] JAWA BARAT
KAB/KOTA : [02] SUKABUMI
KECAMATAN : [111] SIMPENAN

Data Kemendagri			MFD 2021 Semester 2			
No	Kode	Nama Desa	No	Kode	Nama Desa	Status*
1	32.02.02.2004	CIHAUR	1	3202111001	CIHAUR	2
2	32.02.02.2003	KERTAJAYA	2	3202111002	KERTAJAYA	2
3	32.02.02.2002	LOJI	3	3202111003	LOJI	2
4	32.02.02.2001	CIDADAP	4	3202111004	CIDADAP	1
5	32.02.02.2005	CIBUNTU	5	3202116005	CIBUNTU	2
6	32.02.02.2006	MEKARASIH	6	3202111006	MEKARASIH	2
7	32.02.02.2007	SANGRA-WAYANG	7	3202111007	SANGRA-WAYANG	2

Catatan :
*) 1. Perkotaan
2. Perdesaan

https://jabar.bps.go.id

DAFTAR DESA/KELURAHAN

PROVINSI : [32] JAWA BARAT
KAB/KOTA : [02] SUKABUMI
KECAMATAN : [120] WARUNG KIARA

Data Kemendagri			MFD 2021 Semester 2			
No	Kode	Nama Desa	No	Kode	Nama Desa	Status*
1	32.02.09.2005	HEGARMANAH	1	3202120002	HEGARMANAH	2
2	32.02.09.2004	BANTAR-KALONG	2	3202120003	BANTAR-KALONG	2
3	32.02.09.2007	SIRNAJAYA	3	3202120004	SIRNAJAYA	2
4	32.02.09.2002	BOJONGKERTA	4	3202120005	BOJONGKERTA	2
5	32.02.09.2006	UBRUG	5	3202120006	UBRUG	1
6	32.02.09.2003	GIRIJAYA	6	3202120007	GIRIJAYA	2
7	32.02.09.2001	WARUNG-KIARA	7	3202120008	WARUNG-KIARA	2
8	32.02.09.2008	SUKAHARJA	8	3202120009	SUKAHARJA	1
9	32.02.09.2012	TARISI	9	3202120010	TARISI	2
10	32.02.09.2011	DAMARRAJA	10	3202120011	DAMARRAJA	2
11	32.02.09.2010	MEKARJAYA	11	3202120012	MEKARJAYA	2
12	32.02.09.2009	KERTAMUKTI	12	3202120013	KERTAMUKTI	2

Catatan :
*) 1. Perkotaan
2. Perdesaan

https://jabar.bps.go.id

PROVINSI : [32] JAWA BARAT
KAB/KOTA : [02] SUKABUMI
KECAMATAN : [121] BANTARGADUNG

Data Kemendagri			MFD 2021 Semester 2			
No	Kode	Nama Desa	No	Kode	Nama Desa	Status*
1	32.02.04.2005	BANTARGE-BANG	1	3202121001	BANTARGE-BANG	2
2	32.02.04.2003	BOJONG-GALING	2	3202121002	BOJONG-GALING	2
3	32.02.04.2001	BANTAR-GADUNG	3	3202121003	BANTAR-GADUNG	2
4	32.02.04.2002	MANGUNJAYA	4	3202121004	MANGUNJAYA	2
5	32.02.04.2004	LIMUSNUNG-GAL	5	3202121005	LIMUSNUNG-GAL	2
6	32.02.04.2006	BUANAJAYA	6	3202121006	BUANAJAYA	2
7	32.02.04.2007	BOYONGSARI	7	3202121007	BOYONGSARI	2

Catatan :
*) 1. Perkotaan
2. Perdesaan

https://jabar.bps.go.id

DAFTAR DESA/KELURAHAN

PROVINSI : [32] JAWA BARAT
KAB/KOTA : [02] SUKABUMI
KECAMATAN : [130] JAMPANG TENGAH

Data Kemendagri			MFD 2021 Semester 2			
No	Kode	Nama Desa	No	Kode	Nama Desa	Status*
1	32.02.08.2003	BANTARPAN-JANG	1	3202130001	BANTARPAN-JANG	2
2	32.02.08.2011	BOJONGTIPAR	2	3202130009	BOJONGTIPAR	2
3	32.02.08.2009	CIJULANG	3	3202130010	CIJULANG	2
4	32.02.08.2005	NANGERANG	4	3202130011	NANGERANG	2
5	32.02.08.2004	BOJONG JENG-KOL	5	3202130012	BOJONG JENG-KOL	2
6	32.02.08.2010	BANTAR AGUNG	6	3202130013	BANTAR AGUNG	2
7	32.02.08.2001	JAMPANG TENGAH	7	3202130014	JAMPANG TENGAH	2
8	32.02.08.2008	PANUM-BANGAN	8	3202130015	PANUM-BANGAN	2
9	32.02.08.2007	SINDANG-RESMI	9	3202130016	SINDANG-RESMI	2
10	32.02.08.2006	TANJUNGSARI	10	3202120017	TANJUNGSARI	2
11	32.02.08.2002	PADABEUNG-HAR	11	3202130018	PADABEUNG-HAR	2

Catatan :
*) 1. Perkotaan
2. Perdesaan

https://jabar.bps.go.id

PROVINSI : [32] JAWA BARAT
KAB/KOTA : [02] SUKABUMI
KECAMATAN : [131] PURABAYA

Data Kemendagri			MFD 2021 Semester 2			
No	Kode	Nama Desa	No	Kode	Nama Desa	Status*
1	32.02.38.2002	NEGLASARI	1	3202131001	NEGLASARI	2
2	32.02.38.2007	CICUKANG	2	3202131002	CICUKANG	2
3	32.02.38.2006	MARGALUYU	3	3202131003	MARGALUYU	2
4	32.02.38.2001	PURABAYA	4	3202131004	PURABAYA	2
5	32.02.38.2003	PAGELARAN	5	3202131005	PAGELARAN	2
6	32.02.38.2005	CITAMIANG	6	3202131006	CITAMIANG	2
7	32.02.38.2004	CIMERANG	7	3202131007	CIMERANG	2

Catatan :
*) 1. Perkotaan
2. Perdesaan

https://jabar.bps.go.id

DAFTAR DESA/KELURAHAN

PROVINSI : [32] JAWA BARAT
KAB/KOTA : [02] SUKABUMI
KECAMATAN : [140] CIKEMBAR

Data Kemendagri			MFD 2021 Semester 2			
No	Kode	Nama Desa	No	Kode	Nama Desa	Status*
1	32.02.10.2006	SUKAMAJU	1	3202140001	SUKAMAJU	2
2	32.02.10.2007	CIBATU	2	3202140002	CIBATU	2
3	32.02.10.2002	PARAKANLIMA	3	3202140003	PARAKANLIMA	2
4	32.02.10.2008	KERTARA-HARJA	4	3202140004	KERTARA-HARJA	1
5	32.02.10.2003	BOJONG	5	3202140005	BOJONG	2
6	32.02.10.2005	BOJONGKEM-BAR	6	3202140006	BOJONGKEM-BAR	2
7	32.02.10.2001	CIKEMBAR	7	3202140007	CIKEMBAR	2
8	32.02.10.2004	CIMANGGU	8	3202140008	CIMANGGU	1
9	32.02.10.2009	SUKAMULYA	9	3202140009	SUKAMULYA	1
10	32.02.10.2010	BOJONGRA-HARJA	10	3202140010	BOJONGRA-HARJA	2

Catatan :
*) 1. Perkotaan
2. Perdesaan

https://jabar.bps.go.id

PROVINSI : [32] JAWA BARAT
KAB/KOTA : [02] SUKABUMI
KECAMATAN : [150] NYALINDUNG

Data Kemendagri			MFD 2021 Semester 2			
No	Kode	Nama Desa	No	Kode	Nama Desa	Status*
1	32.02.39.2008	CISITU	1	3202150001	CISITU	2
2	32.02.39.2001	NYALINDUNG	2	3202150002	NYALINDUNG	1
3	32.02.39.2010	KERTAANG-SANA	3	3202150003	KERTAANG-SANA	2
4	32.02.39.2006	MEKARSARI	4	3202150004	MEKARSARI	2
5	32.02.39.2004	BOJONGKA-LONG	5	3202150005	BOJONGKA-LONG	2
6	32.02.39.2009	BOJONGSARI	6	3202150006	BOJONGSARI	2
7	32.02.39.2003	SUKAMAJU	7	3202150007	SUKAMAJU	2
8	32.02.39.2007	WARUNGREJA	8	3202150008	WARUNGREJA	2
9	32.02.39.2002	NEGLASARI	9	3202150009	NEGLASARI	2
10	32.02.39.2005	CIJANGKAR	10	3202150010	CIJANGKAR	2

Catatan :
*) 1. Perkotaan
2. Perdesaan

https://jabar.bps.go.id

DAFTAR DESA/KELURAHAN

PROVINSI : [32] JAWA BARAT
KAB/KOTA : [02] SUKABUMI
KECAMATAN : [160] GEGERBITUNG

Data Kemendagri			MFD 2021 Semester 2			
No	Kode	Nama Desa	No	Kode	Nama Desa	Status*
1	32.02.40.2003	CIENGANG	1	3202160001	CIENGANG	2
2	32.02.40.2006	SUKAMANAH	2	3202160002	SUKAMANAH	2
3	32.02.40.2001	GEGERBITUNG	3	3202160003	GEGERBITUNG	1
4	32.02.40.2002	CIJUREY	4	3202160004	CIJUREY	2
5	32.02.40.2004	KARANGJAYA	5	3202160005	KARANGJAYA	2
6	32.02.40.2007	BUNIWANGI	6	3202160006	BUNIWANGI	2
7	32.02.40.2005	CARINGIN	7	3202160007	CARINGIN	2

Catatan :
*) 1. Perkotaan
2. Perdesaan

https://jabar.bps.go.id

PROVINSI : [32] JAWA BARAT
KAB/KOTA : [02] SUKABUMI
KECAMATAN : [170] SUKARAJA

Data Kemendagri			MFD 2021 Semester 2			
No	Kode	Nama Desa	No	Kode	Nama Desa	Status*
1	32.02.33.2008	SELAWANGI	1	3202170011	SELAWANGI	1
2	32.02.33.2001	PASIRHALANG	2	3202170012	PASIRHALANG	1
3	32.02.33.2004	SUKARAJA	3	3202170013	SUKARAJA	1
4	32.02.33.2007	SUKAMEKAR	4	3202170014	SUKAMEKAR	1
5	32.02.33.2006	CISARUA	5	3202170015	CISARUA	2
6	32.02.33.2005	LIMBANGAN	6	3202170016	LIMBANGAN	1
7	32.02.33.2003	LANGENSARI	7	3202170017	LANGENSARI	2
8	32.02.33.2002	SELAAWI	8	3202170018	SELAAWI	1
9	32.02.33.2009	MARGALUYU	9	3202170021	MARGALUYU	2

Catatan :
*) 1. Perkotaan
2. Perdesaan

https://jabar.bps.go.id

DAFTAR DESA/KELURAHAN

PROVINSI : [32] JAWA BARAT
KAB/KOTA : [02] SUKABUMI
KECAMATAN : [171] KEBONPEDES

Data Kemendagri			MFD 2021 Semester 2			
No	Kode	Nama Desa	No	Kode	Nama Desa	Status*
1	32.02.34.2004	SASAGARAN	1	3202171001	SASAGARAN	1
2	32.02.34.2005	JAMBENENG-GANG	2	3202171002	JAMBENENG-GANG	1
3	32.02.34.2002	CIKARET	3	3202171003	CIKARET	1
4	32.02.34.2001	KEBONPEDES	4	3202171004	KEBONPEDES	1
5	32.02.34.2003	BOJONG-SAWAH	5	3202171005	BOJONG-SAWAH	1

Catatan :
*) 1. Perkotaan
2. Perdesaan

https://jabar.bps.go.id

PROVINSI : [32] JAWA BARAT
KAB/KOTA : [02] SUKABUMI
KECAMATAN : [172] CIREUNGHAS

Data Kemendagri			MFD 2021 Semester 2			
No	Kode	Nama Desa	No	Kode	Nama Desa	Status*
1	32.02.35.2002	CIPURUT	1	3202172001	CIPURUT	1
2	32.02.35.2001	CIREUNGHAS	2	3202172002	CIREUNGHAS	2
3	32.02.35.2003	BENCOY	3	3202172003	BENCOY	2
4	32.02.35.2004	CIKURUTUG	4	3202172004	CIKURUTUG	2
5	32.02.35.2005	TEGALPAN-JANG	5	3202172005	TEGALPAN-JANG	2

Catatan :
*) 1. Perkotaan
2. Perdesaan

https://jabar.bps.go.id

DAFTAR DESA/KELURAHAN

PROVINSI : [32] JAWA BARAT
KAB/KOTA : [02] SUKABUMI
KECAMATAN : [173] SUKALARANG

Data Kemendagri			MFD 2021 Semester 2			
No	Kode	Nama Desa	No	Kode	Nama Desa	Status*
1	32.02.36.2005	SEMPLAK	1	3202173001	SEMPLAK	2
2	32.02.36.2006	PRIANGAN-JAYA	2	3202173002	PRIANGAN-JAYA	2
3	32.02.36.2004	TITISAN	3	3202173003	TITISAN	2
4	32.02.36.2003	CIMANGKOK	4	3202173004	CIMANGKOK	2
5	32.02.36.2001	SUKALARANG	5	3202173005	SUKALARANG	1
6	32.02.36.2002	SUKAMAJU	6	3202173006	SUKAMAJU	1

Catatan :
*) 1. Perkotaan
2. Perdesaan

https://jabar.bps.go.id

PROVINSI : [32] JAWA BARAT
KAB/KOTA : [02] SUKABUMI
KECAMATAN : [180] SUKABUMI

Data Kemendagri			MFD 2021 Semester 2			
No	Kode	Nama Desa	No	Kode	Nama Desa	Status*
1	32.02.32.2001	PARUNGSEAH	1	3202180001	PARUNGSEAH	1
2	32.02.32.2004	WARNASARI	2	3202180002	WARNASARI	1
3	32.02.32.2005	SUKAJAYA	3	3202180003	SUKAJAYA	1
4	32.02.32.2002	SUNDAJAYA GIRANG	4	3202180004	SUDAJAYA GIRANG	1
5	32.02.32.2003	KARAWANG	5	3202180005	KARAWANG	1
6	32.02.32.2006	PERBAWATI	6	3202180006	PERBAWATI	1

Catatan :
*) 1. Perkotaan
2. Perdesaan

https://jabar.bps.go.id

DAFTAR DESA/KELURAHAN

PROVINSI : [32] JAWA BARAT
KAB/KOTA : [02] SUKABUMI
KECAMATAN : [190] KADUDAMPIT

Data Kemendagri			MFD 2021 Semester 2			
No	Kode	Nama Desa	No	Kode	Nama Desa	Status*
1	32.02.30.2003	MUARADUA	1	3202190001	MUARADUA	1
2	32.02.30.2002	CITAMIANG	2	3202190002	CITAMIANG	1
3	32.02.30.2009	CIKAHURIPAN	3	3202190003	CIKAHURIPAN	2
4	32.02.30.2005	SUKAMANIS	4	3202190004	SUKAMANIS	2
5	32.02.30.2001	KADUDAMPIT	5	3202190005	KADUDAMPIT	2
6	32.02.30.2004	GEDE PANG-RANGO	6	3202190006	GEDE PANG-RANGO	1
7	32.02.30.2008	SUKAMAJU	7	3202192007	SUKAMAJU	1
8	32.02.30.2007	CIPETIR	8	3202192008	CIPETIR	2
9	32.02.30.2006	UNDRUS BINANGUN	9	3202192009	UNDRUS BINANGUN	2

Catatan :
*) 1. Perkotaan
2. Perdesaan

https://jabar.bps.go.id

PROVINSI : [32] JAWA BARAT
KAB/KOTA : [02] SUKABUMI
KECAMATAN : [200] CISAAT

Data Kemendagri			MFD 2021 Semester 2			
No	Kode	Nama Desa	No	Kode	Nama Desa	Status*
1	32.02.29.2010	PADAASIH	1	3202200007	PADAASIH	1
2	32.02.29.2004	CISAAT	2	3202200008	CISAAT	1
3	32.02.29.2006	BABAKAN	3	3202200009	BABAKAN	2
4	32.02.29.2007	SUKAMANTRI	4	3202200010	SUKAMANTRI	1
5	32.02.29.2003	SUKAMANAH	5	3202200011	SUKAMANAH	1
6	32.02.29.2005	NAGRAK	6	3202200012	NAGRAK	1
7	32.02.29.2008	CIBATU	7	3202200013	CIBATU	1
8	32.02.29.2011	CIBOLANG KALER	8	3202200014	CIBOLANG KALER	1
9	32.02.29.2012	KUTASIRNA	9	3202200015	KUTASIRNA	1
10	32.02.29.2009	SELAJAMBE	10	3202200016	SELAJAMBE	1
11	32.02.29.2002	SUKASARI	11	3202200017	SUKASARI	1
12	32.02.29.2001	GUNUNGJAYA	12	3202200018	GUNUNGJAYA	1
13	32.02.29.2013	SUKARESMI	13	3202200019	SUKARESMI	1

Catatan :
*) 1. Perkotaan
2. Perdesaan

https://jabar.bps.go.id

DAFTAR DESA/KELURAHAN

PROVINSI : [32] JAWA BARAT
KAB/KOTA : [02] SUKABUMI
KECAMATAN : [201] GUNUNGGURUH

Data Kemendagri			MFD 2021 Semester 2			
No	Kode	Nama Desa	No	Kode	Nama Desa	Status*
1	32.02.27.2004	SIRNARESMI	1	3202201001	SIRNARESMI	1
2	32.02.27.2005	KEBONMANG-GU	2	3202201002	KEBONMANG-GU	1
3	32.02.27.2002	GUNUNG GURUH	3	3202201003	GUNUNG GURUH	1
4	32.02.27.2001	CIKUJANG	4	3202201004	CIKUJANG	1
5	32.02.27.2003	CIBENTANG	5	3202201005	CIBENTANG	1
6	32.02.27.2006	CIBOLANG	6	3202201006	CIBOLANG	1
7	32.02.27.2007	MANGKALAYA	7	3202201007	MANGKALAYA	1

Catatan :
*) 1. Perkotaan
2. Perdesaan

https://jabar.bps.go.id

PROVINSI : [32] JAWA BARAT
KAB/KOTA : [02] SUKABUMI
KECAMATAN : [210] CIBADAK

Data Kemendagri			MFD 2021 Semester 2			
No	Kode	Nama Desa	No	Kode	Nama Desa	Status*
1	32.02.11.2005	NEGLASARI	1	3202210001	NEGLASARI	2
2	32.02.11.2007	TENJOJAYA	2	3202210002	TENJOJAYA	1
3	32.02.11.2002	SEKARWANGI	3	3202210003	SEKARWANGI	1
4	32.02.11.2010	BATUNUNG-GAL	4	3202210009	BATUNUNG-GAL	1
5	32.02.11.2004	KARANG TENGAH	5	3202210010	KARANG TENGAH	1
6	32.02.11.1001	CIBADAK	6	3202210011	CIBADAK	1
7	32.02.11.2006	WARNAJATI	7	3202210012	WARNAJATI	1
8	32.02.11.2009	SUKASIRNA	8	3202210013	SUKASIRNA	2
9	32.02.11.2003	PAMURUYAN	9	3202210014	PAMURUYAN	1
10	32.02.11.2008	CIHEULANG-TONGGOH	10	3202210015	CIHEULANG-TONGGOH	1

Catatan :
*) 1. Perkotaan
2. Perdesaan

https://jabar.bps.go.id

DAFTAR DESA/KELURAHAN

PROVINSI : [32] JAWA BARAT
KAB/KOTA : [02] SUKABUMI
KECAMATAN : [211] CICANTAYAN

Data Kemendagri			MFD 2021 Semester 2			
No	Kode	Nama Desa	No	Kode	Nama Desa	Status*
1	32.02.28.2006	HEGARMANAH	1	3202211001	HEGARMANAH	2
2	32.02.28.2001	CICANTAYAN	2	3202211002	CICANTAYAN	1
3	32.02.28.2005	CIMAHI	3	3202211003	CIMAHI	1
4	32.02.28.2004	CISANDE	4	3202211004	CISANDE	1
5	32.02.28.2003	CIJALINGAN	5	3202211005	CIJALINGAN	1
6	32.02.28.2002	LEMBUR-SAWAH	6	3202211006	LEMBUR-SAWAH	1
7	32.02.28.2007	SUKADAMAI	7	3202211007	SUKADAMAI	1
8	32.02.28.2008	CIMANGGIS	8	3202211008	CIMANGGIS	2

Catatan :
*) 1. Perkotaan
2. Perdesaan

https://jabar.bps.go.id

PROVINSI : [32] JAWA BARAT
KAB/KOTA : [02] SUKABUMI
KECAMATAN : [212] CARINGIN

Data Kemendagri			MFD 2021 Semester 2			
No	Kode	Nama Desa	No	Kode	Nama Desa	Status*
1	32.02.31.2005	CIJENGKOL	1	3202212001	CIJENGKOL	2
2	32.02.31.2006	MEKARJAYA	2	3202212002	MEKARJAYA	2
3	32.02.31.2003	TALAGA	3	3202212003	TALAGA	1
4	32.02.31.2003	CARINGIN KULON	4	3202212004	CARINGIN KULON	2
5	32.02.31.2001	CARINGIN WETAN	5	3202212005	CARINGIN WETAN	2
6	32.02.31.2004	SEUSEUPAN	6	3202212006	SEUSEUPAN	2
7	32.02.31.2002	SUKAMULYA	7	3202212007	SUKAMULYA	2
8	32.02.31.2008	CIKEMBANG	8	3202212008	CIKEMBANG	2
9	32.02.31.2009	PASIRDATAR INDAH	9	3202212009	PASIRDATAR INDAH	2

Catatan :
*) 1. Perkotaan
2. Perdesaan

https://jabar.bps.go.id

DAFTAR DESA/KELURAHAN

PROVINSI : [32] JAWA BARAT
KAB/KOTA : [02] SUKABUMI
KECAMATAN : [220] NAGRAK

Data Kemendagri			MFD 2021 Semester 2			
No	Kode	Nama Desa	No	Kode	Nama Desa	Status*
1	32.02.31.2004	CISARUA	1	3202220001	CISARUA	1
2	32.02.31.2009	BALEKAM-BANG	2	3202220002	BALEKAM-BANG	1
3	32.02.31.2013	NAGRAK SELA-TAN	3	3202220003	NAGRAK SELA-TAN	1
4	32.02.31.2003	NAGRAK UTARA	4	3202220004	NAGRAK UTARA	1
5	32.02.12.2001	KALAPAREA	5	3202220005	KALAPAREA	1
6	32.02.12.2011	DARMAREJA	6	3202220006	DARMAREJA	2
7	32.02.12.2014	GIRIJAYA	7	3202220007	GIRIJAYA	2
8	32.02.12.2010	BABAKAN PAN-JANG	8	3202220008	BABAKAN PAN-JANG	2
9	32.02.12.2002	PAWENANG	9	3202220009	PAWENANG	1
10	32.02.12.2012	CIHANYAWAR	10	3202220010	CIHANYAWAR	2

Catatan :
*) 1. Perkotaan
2. Perdesaan

https://jabar.bps.go.id

PROVINSI : [32] JAWA BARAT
KAB/KOTA : [02] SUKABUMI
KECAMATAN : [221] CIAMBAR

Data Kemendagri			MFD 2021 Semester 2			
No	Kode	Nama Desa	No	Kode	Nama Desa	Status*
1	32.02.47.2004	MUNJUL	1	3202221001	MUNJUL	2
2	32.02.47.2001	CIAMBAR	2	3202221002	CIAMBAR	1
3	32.02.47.2002	GINANJAR	3	3202221003	GINANJAR	1
4	32.02.47.2003	WANGUNJAYA	4	3202221004	WANGUNJAYA	2
5	32.02.47.2006	CIBUNARJAYA	5	3202221005	CIBUNARJAYA	1
6	32.02.47.2005	AMBARJAYA	6	3202221006	AMBARJAYA	2

Catatan :
*) 1. Perkotaan
2. Perdesaan

https://jabar.bps.go.id

DAFTAR DESA/KELURAHAN

PROVINSI : [32] JAWA BARAT
KAB/KOTA : [02] SUKABUMI
KECAMATAN : [230] CICURUG

Data Kemendagri			MFD 2021 Semester 2			
No	Kode	Nama Desa	No	Kode	Nama Desa	Status*
1	32.02.16.2011	MEKARSARI	1	3202230001	MEKARSARI	1
2	32.02.16.2002	NYANGKOWEK	2	3202230002	NYANGKOWEK	1
3	32.02.16.2007	PURWASARI	3	3202230003	PURWASARI	1
4	32.02.16.2008	CARINGIN	4	3202230004	CARINGIN	1
5	32.02.16.2012	BANGBAYANG	5	3202230005	BANGBAYANG	1
6	32.02.16.2006	CISAAT	6	3202230006	CISAAT	1
7	32.02.16.2003	TENJOYALAYA	7	3202230007	TENJOYALAYA	1
8	32.02.16.2005	PASAWAHAN	8	3202230008	PASAWAHAN	1
9	32.02.16.1001	CICURUG	9	3202230009	CICURUG	1
10	32.02.16.2013	NANGGERANG	10	3202230010	NANGGERANG	1
11	32.02.16.2009	TENJOAYU	11	3202230011	TENJOAYU	1
12	32.02.16.2004	BENDA	12	3202230012	BENDA	1
13	32.02.16.2010	KUTAJAYA	13	3202230013	KUTAJAYA	1

Catatan :
*) 1. Perkotaan
2. Perdesaan

https://jabar.bps.go.id

PROVINSI : [32] JAWA BARAT
KAB/KOTA : [02] SUKABUMI
KECAMATAN : [240] CIDAHU

Data Kemendagri			MFD 2021 Semester 2			
No	Kode	Nama Desa	No	Kode	Nama Desa	Status*
1	32.02.17.2003	PONDOK KASO TENGAH	1	3202240001	PONDOK KASO TENGAH	2
2	32.02.17.2008	PASIRDOTON	2	3202240002	PASIRDOTON	1
3	32.02.17.2001	PONDOK KASO TONGGOH	3	3202240003	PONDOK KASO TONGGOH	1
4	32.02.17.2002	BABAKAN PARI	4	3202240004	BABAKAN PARI	1
5	32.02.17.2005	TANGKIL	5	3202240005	TANGKIL	2
6	32.02.17.2006	JAYABAKTI	6	3202240006	JAYABAKTI	1
7	32.02.17.2004	CIDAHU	7	3202240007	CIDAHU	2
8	32.02.17.2007	GIRIJAYA	8	3202240008	GIRIJAYA	2

Catatan :
*) 1. Perkotaan
2. Perdesaan

https://jabar.bps.go.id

DAFTAR DESA/KELURAHAN

PROVINSI : [32] JAWA BARAT
KAB/KOTA : [02] SUKABUMI
KECAMATAN : [250] PARAKAN SALAK

Data Kemendagri			MFD 2021 Semester 2			
No	Kode	Nama Desa	No	Kode	Nama Desa	Status*
1	32.02.15.2001	SUKATANI	1	3202250001	SUKATANI	2
2	32.02.15.2002	SUKAKERSA	2	3202250002	SUKAKERSA	2
3	32.02.15.2003	BOJONG LONGOK	3	3202250003	BOJONG LONGOK	1
4	32.02.15.2004	BOJONGASIH	4	3202250004	BOJONGASIH	2
5	32.02.15.2005	LEBAKSARI	5	3202250005	LEBAKSARI	2
6	32.02.15.2006	PARAKAN SALAK	6	3202250006	PARAKAN SALAK	1

Catatan :
*) 1. Perkotaan
2. Perdesaan

https://jabar.bps.go.id

PROVINSI : [32] JAWA BARAT
KAB/KOTA : [02] SUKABUMI
KECAMATAN : [260] PARUNGKUDA

Data Kemendagri			MFD 2021 Semester 2			
No	Kode	Nama Desa	No	Kode	Nama Desa	Status*
1	32.02.13.2002	PALASARI HILIR	1	3202260002	PALASARI HILIR	2
2	32.02.13.2005	SUNDA-WENANG	2	3202260003	SUNDA-WENANG	1
3	32.02.13.2001	PARUNGKUDA	3	3202260004	PARUNGKUDA	1
4	32.02.13.2007	LANGENSARI	4	3202260008	LANGENSARI	2
5	32.02.13.2006	BOJONG KOKOSAN	5	3202260009	BOJONG KOKOSAN	1
6	32.02.13.2003	KOMPA	6	3202260010	KOMPA	1
7	32.02.13.2004	PONDOK KASO LANDEUH	7	3202260011	PONDOK KASO LANDEUH	1
8	32.02.13.2008	BABAKANJAYA	8	3202260012	BABAKANJAYA	1

Catatan :
*) 1. Perkotaan
2. Perdesaan

https://jabar.bps.go.id

DAFTAR DESA/KELURAHAN

PROVINSI : [32] JAWA BARAT
KAB/KOTA : [02] SUKABUMI
KECAMATAN : [261] BOJONGGENTENG

Data Kemendagri			MFD 2021 Semester 2			
No	Kode	Nama Desa	No	Kode	Nama Desa	Status*
1	32.02.14.2001	BEREKAH	1	3202261001	BEREKAH	2
2	32.02.14.2002	BOJONG GEN-TENG	2	3202261002	BOJONG GEN-TENG	1
3	32.02.14.2003	BOJONG GALING	3	3202261003	BOJONG GALING	2
4	32.02.14.2004	CIBODAS	4	3202261004	CIBODAS	1
5	32.02.14.2005	CIPANENGAH	5	3202261005	CIPANENGAH	2

Catatan :
*) 1. Perkotaan
2. Perdesaan

https://jabar.bps.go.id

PROVINSI : [32] JAWA BARAT
KAB/KOTA : [02] SUKABUMI
KECAMATAN : [270] KALAPA NUNGGAL

Data Kemendagri			MFD 2021 Semester 2			
No	Kode	Nama Desa	No	Kode	Nama Desa	Status*
1	32.02.18.2006	WALANGSARI	1	3202270001	WALANGSARI	1
2	32.02.18.2002	PALASARI GIRANG	2	3202270002	PALASARI GIRANG	1
3	32.02.18.2001	KALAPANUNG-GAL	3	3202270003	KALAPANUNG-GAL	1
4	32.02.18.2005	KADUNUNG-GAL	4	3202270004	KADUNUNG-GAL	1
5	32.02.18.2004	MAKASARI	5	3202270005	MAKASARI	2
6	32.02.18.2007	GUNUNG ENDUT	6	3202270006	GUNUNG ENDUT	2
7	32.02.18.2003	PULOSARI	7	3202270007	PULOSARI	2

Catatan :
*) 1. Perkotaan
2. Perdesaan

https://jabar.bps.go.id

DAFTAR DESA/KELURAHAN

PROVINSI : [32] JAWA BARAT
KAB/KOTA : [02] SUKABUMI
KECAMATAN : [280] CIKIDANG

Data Kemendagri			MFD 2021 Semester 2			
No	Kode	Nama Desa	No	Kode	Nama Desa	Status*
1	32.02.06.2001	SAMPORA	1	3202280001	SAMPORA	2
2	32.02.06.2002	CIJAMBE	2	3202280002	CIJAMBE	2
3	32.02.06.2003	CIKIRAY	3	3202280003	CIKIRAY	2
4	32.02.06.2004	MEKARNANG-KA	4	3202280004	MEKARNANG-KA	2
5	32.02.06.2005	CIKIDANG	5	3202280005	CIKIDANG	2
6	32.02.06.2006	GUNUNG MALANG	6	3202280006	GUNUNG MALANG	2
7	32.02.06.2007	NANGKA-KONENG	7	3202280007	NANGKA-KONENG	2
8	32.02.06.2008	PANGKALAN	8	3202280008	PANGKALAN	2
9	32.02.06.2009	BUMISARI	9	3202280009	BUMISARI	2
10	32.02.06.2010	CICAREUH	10	3202280010	CICAREUH	2
11	32.02.06.2011	TAMANSARI	11	3202280011	TAMANSARI	2
12	32.02.06.2012	CIKARAE THOYIBAH	12	3202280012	CIKARAE THOYIBAH	2

Catatan :
*) 1. Perkotaan
2. Perdesaan

https://jabar.bps.go.id

PROVINSI : [32] JAWA BARAT
KAB/KOTA : [02] SUKABUMI
KECAMATAN : [290] CISOLOK

Data Kemendagri			MFD 2021 Semester 2			
No	Kode	Nama Desa	No	Kode	Nama Desa	Status*
1	32.02.05.2002	PASIRBARU	1	3202290001	PASIRBARU	2
2	32.02.05.2003	CIKAHURIPAN	2	3202290002	CIKAHURIPAN	2
3	32.02.05.2001	CISOLOK	3	3202290003	CISOLOK	2
4	32.02.05.2008	KARANGPAPAK	4	3202290004	KARANGPAPAK	2
5	32.02.05.2009	SIRNARESMI	5	3202290012	SIRNARESMI	2
6	32.02.05.2010	CICADAS	6	3202290013	CICADAS	2
7	32.02.05.2004	CIKELAT	7	3202290014	CIKELAT	2
8	32.02.05.2006	GUNUNG KRAMAT	8	3202290015	GUNUNG KRAMAT	2
9	32.02.05.2007	GUNUNG TANJUNG	9	3202290016	GUNUNG TANJUNG	2
10	32.02.05.2005	CARINGIN	10	3202290017	CARINGIN	2
11	32.02.05.2013	SUKARAME	11	3202290018	SUKARAME	2
12	32.02.05.2012	WANGUNSARI	12	3202290019	WANGUNSARI	2
13	32.02.05.2011	WANAJAYA	13	3202290020	WANAJAYA	2

Catatan :
*) 1. Perkotaan
2. Perdesaan

https://jabar.bps.go.id

DAFTAR DESA/KELURAHAN

PROVINSI : [32] JAWA BARAT
KAB/KOTA : [02] SUKABUMI
KECAMATAN : [291] CIKAKAK

Data Kemendagri			MFD 2021 Semester 2			
No	Kode	Nama Desa	No	Kode	Nama Desa	Status*
1	32.02.03.2002	CIMAJA	1	3202291001	CIMAJA	2
2	32.02.03.2001	CIKAKAK	2	3202291002	CIKAKAK	1
3	32.02.03.2004	SUKAMAJU	3	3202291003	SUKAMAJU	2
4	32.02.03.2005	CILEUNGSING	4	3202291004	CILEUNGSING	2
5	32.02.03.2003	RIDOGALIH	5	3202291005	RIDOGALIH	2
6	32.02.03.2006	MARGALAK-SANA	6	3202291006	MARGALAK-SANA	2
7	32.02.03.2007	SIRNARASA	7	3202291007	SIRNARASA	2
8	32.02.03.2008	GANDASOLI	8	3202291008	GANDASOLI	2
9	32.02.03.2009	CIRENDANG	9	3202291009	CIRENDANG	2

Catatan :
*) 1. Perkotaan
2. Perdesaan

https://jabar.bps.go.id

PROVINSI : [32] JAWA BARAT
KAB/KOTA : [02] SUKABUMI
KECAMATAN : [300] KABANDUNGAN

Data Kemendagri			MFD 2021 Semester 2			
No	Kode	Nama Desa	No	Kode	Nama Desa	Status*
1	32.02.19.2005	MEKARJAYA	1	3202300001	MEKARJAYA	2
2	32.02.19.2004	TUGU BANDUNG	2	3202300002	TUGU BANDUNG	2
3	32.02.19.2001	KABANDUNGAN	3	3202300003	KABANDUNGAN	2
4	32.02.19.2002	CIPEUTEUY	4	3202300004	CIPEUTEUY	2
5	32.02.19.2003	CIHAMERANG	5	3202300005	CIHAMERANG	2
6	32.02.19.2006	CIANAGA	6	3202300006	CIANAGA	2

Catatan :
*) 1. Perkotaan
2. Perdesaan

https://jabar.bps.go.id

https://jabar.bps.go.id

KABUPATEN CIANJUR

https://jabar.bps.go.id

https://jabar.bps.go.id

PROVINSI : [32] JAWA BARAT
KAB/KOTA : [03] CIANJUR

Data Kemendagri			MFD 2021 Semester 2		
No	Kode	Nama Kecamatan	No	Kode	Nama Kecamatan
1	32.03.22	AGRABINTA	1	3203010	AGRABINTA
2	32.03.30	LELES	2	3203011	LELES
3	32.03.21	SINDANGBARANG	3	3203020	SINDANGBARANG
4	32.03.23	CIDAUN	4	3203030	CIDAUN
5	32.03.24	NARINGGUL	5	3203040	NARINGGUL
6	32.03.20	CIBINONG	6	3203050	CIBINONG
7	32.03.26	CIKADU	7	3203051	CIKADU
8	32.03.19	TANGGEUNG	8	3203060	TANGGEUNG
9	32.03.32	PASIRKUDA	9	3203061	PASIRKUDA
10	32.03.17	KADUPANDAK	10	3203070	KADUPANDAK
11	32.03.29	CIJATI	11	3203071	CIJATI
12	32.03.16	TAKOKAK	12	3203080	TAKOKAK
13	32.03.14	SUKANAGARA	13	3203090	SUKANAGARA
14	32.03.18	PAGELARAN	14	3203100	PEGELARAN
15	32.03.15	CAMPAKA	15	3203110	CAMPAKA
16	32.03.25	CAMPAKAMULYA	16	3203111	CAMPAKAMULYA
17	32.03.03	CIBEBER	17	3203120	CIBEBER
18	32.03.02	WARUNGKONDANG	18	3203130	WARUNGKONDANG
19	32.03.27	GEKBRONG	19	3203131	GEKBRONG
20	32.03.04	CILAKU	20	3203140	CILAKU
21	32.03.09	SUKALUYU	21	3203150	SUKALUYU
22	32.03.06	BOJONGPICUNG	22	3203160	BOJONGPICUNG

https://jabar.bps.go.id

DAFTAR KECAMATAN

PROVINSI : [32] JAWA BARAT
KAB/KOTA : [03] CIANJUR

Data Kemendagri			MFD 2021 Semester 2		
No	Kode	Nama Kecamatan	No	Kode	Nama Kecamatan
23	32.03.31	HAURWANGI	23	3203161	HAURWANGI
24	32.03.05	CIRANJANG	24	3203170	CIRANJANG
25	32.03.08	MANDE	25	3203180	MANDE
26	32.03.07	KARANGTENGAH	26	3203190	KARANGTENGAH
27	32.03.01	CIANJUR	27	3203200	CIANJUR
28	32.03.11	CUGENANG	28	3203210	CUGENANG
29	32.03.10	PACET	29	3203220	PACET
30	32.03.28	CIPANAS	30	3203221	CIPANAS
31	32.03.13	SUKARESMI	31	3203230	SUKARESMI
32	32.03.12	CIKALONGKULON	32	3203240	CIKALONGKULON

https://jabar.bps.go.id

JUMLAH DESA/KELURAHAN PER KECAMATAN

PROVINSI : [32] JAWA BARAT
KAB/KOTA : [03] CIANJUR

Data Kemendagri				MFD 2021 Semester 2			
No	Kode	Nama Kecamatan	Jml Desa	No	Kode	Nama Kecamatan	Jml Desa
1	32.03.22	AGRABINTA	11	1	3203010	AGRABINTA	11
2	32.03.30	LELES	12	2	3203011	LELES	12
3	32.03.21	SINDANGBARANG	11	3	3203020	SINDANGBARANG	11
4	32.03.23	CIDAUN	14	4	3203030	CIDAUN	14
5	32.03.24	NARINGGUL	11	5	3203040	NARINGGUL	11
6	32.03.20	CIBINONG	14	6	3203050	CIBINONG	14
7	32.03.26	CIKADU	10	7	3203051	CIKADU	10
8	32.03.19	TANGGEUNG	12	8	3203060	TANGGEUNG	12
9	32.03.32	PASIRKUDA	9	9	3203061	PASIRKUDA	9
10	32.03.17	KADUPANDAK	14	10	3203070	KADUPANDAK	14
11	32.03.29	CIJATI	10	11	3203071	CIJATI	10
12	32.03.16	TAKOKAK	9	12	3203080	TAKOKAK	9
13	32.03.14	SUKANAGARA	10	13	3203090	SUKANAGARA	10
14	32.03.18	PAGELARAN	14	14	3203100	PEGELARAN	14
15	32.03.15	CAMPAKA	11	15	3203110	CAMPAKA	11
16	32.03.25	CAMPAKAMULYA	5	16	3203111	CAMPAKAMULYA	5
17	32.03.03	CIBEBER	18	17	3203120	CIBEBER	18
18	32.03.02	WARUNGKON-DANG	11	18	3203130	WARUNGKON-DANG	11
19	32.03.27	GEKBRONG	8	19	3203131	GEKBRONG	8
20	32.03.04	CILAKU	10	20	3203140	CILAKU	10
21	32.03.09	SUKALUYU	10	21	3203150	SUKALUYU	10

https://jabar.bps.go.id

JUMLAH DESA/KELURAHAN PER KECAMATAN

PROVINSI : [32] JAWA BARAT
KAB/KOTA : [03] CIANJUR

Data Kemendagri				MFD 2021 Semester 2			
No	Kode	Nama Kecamatan	Jml Desa	No	Kode	Nama Kecamatan	Jml Desa
23	32.03.31	HAURWANGI	8	23	3203161	HAURWANGI	8
24	32.03.05	CIRANJANG	9	24	3203170	CIRANJANG	9
25	32.03.08	MANDE	12	25	3203180	MANDE	12
26	32.03.07	KARANGTENGAH	16	26	3203190	KARANGTENGAH	16
27	32.03.01	CIANJUR	11	27	3203200	CIANJUR	11
28	32.03.11	CUGENANG	16	28	3203210	CUGENANG	16
29	32.03.10	PACET	7	29	3203220	PACET	7
30	32.03.28	CIPANAS	7	30	3203221	CIPANAS	7
31	32.03.13	SUKARESMI	11	31	3203230	SUKARESMI	11
32	32.03.12	CIKALONGKULON	18	32	3203240	CIKALONGKULON	18

https://jabar.bps.go.id

PROVINSI : [32] JAWA BARAT
KAB/KOTA : [03] CIANJUR
KECAMATAN : [010] AGRABINTA

Data Kemendagri			MFD 2021 Semester 2			
No	Kode	Nama Desa	No	Kode	Nama Desa	Status*
1	32.03.22.2010	SINARLAUT	1	3203010001	SINARLAUT	2
2	32.03.22.2005	BOJONGKASO	2	3203010002	BOJONGKASO	2
3	32.03.22.2004	SUKAMANAH	3	3203010003	SUKAMANAH	2
4	32.03.22.2007	WANASARI	4	3203010004	WANASARI	2
5	32.03.22.2016	KARANGSARI	5	3203010007	KARANGSARI	2
6	32.03.22.2014	NEGLASARI	6	3203010008	NEGLASARI	2
7	32.03.22.2017	MULYASARI	7	3203010009	MULYASARI	2
8	32.03.22.2006	BUNISARI	8	3203010010	BUNISARI	2
9	32.03.22.2019	MEKARSARI	9	3203010011	MEKARSARI	2
10	32.03.22.2018	TANJUNGSARI	10	3203010012	TANJUNGSARI	2
11	32.03.22.2022	WANGUNJAYA	11	3203010013	WANGUNJAYA	2

https://jabar.bps.go.id

Catatan :
*) 1. Perkotaan
2. Perdesaan

DAFTAR DESA/KELURAHAN

PROVINSI : [32] JAWA BARAT
KAB/KOTA : [03] CIANJUR
KECAMATAN : [011] LELES

Data Kemendagri			MFD 2021 Semester 2			
No	Kode	Nama Desa	No	Kode	Nama Desa	Status*
1	32.03.30.2001	PUSAKASARI	1	3203011001	PUSAKASARI	2
2	32.03.30.2002	NAGASARI	2	3203011002	NAGASARI	2
3	32.03.30.2003	SUKAJAYA	3	3203011003	SUKAJAYA	2
4	32.03.30.2004	SUKAMULYA	4	3203011004	SUKAMULYA	2
5	32.03.30.2005	PURABAYA	5	3203011005	PURABAYA	2
6	32.03.30.2006	SUKASIRNA	6	3203011006	SUKASIRNA	2
7	32.03.30.2007	WALAHIR	7	3203011007	WALAHIR	2
8	32.03.30.2008	PUNCAK WANGI	8	3203011008	PUNCAK WANGI	2
9	32.03.30.2009	SIRNASARI	9	3203011009	SIRNASARI	2
10	32.03.30.2010	KARYAMUKTI	10	3203011010	KARYAMUKTI	2
11	32.03.30.2011	MANDALA-WANGI	11	3203011011	MANDALA-WANGI	2
12	32.03.30.2012	SINDANGSARI	12	3203011012	SINDANGSARI	2

Catatan :
*) 1. Perkotaan
2. Perdesaan

https://jabar.bps.go.id

PROVINSI : [32] JAWA BARAT
KAB/KOTA : [03] CIANJUR
KECAMATAN : [020] SINDANGBARANG

Data Kemendagri			MFD 2021 Semester 2			
No	Kode	Nama Desa	No	Kode	Nama Desa	Status*
1	32.03.21.2009	HEGARSARI	1	3203020001	HEGARSARI	2
2	32.03.21.2003	JATISARI	2	3203020002	JATISARI	2
3	32.03.21.2006	KERTASARI	3	3203020003	KERTASARI	2
4	32.03.21.2008	TALAGASARI	4	3203020004	TALAGASARI	2
5	32.03.21.2004	SIRNAGALIH	5	3203020005	SIRNAGALIH	2
6	32.03.21.2001	SAGANTEN	6	3203020006	SAGANTEN	2
7	32.03.21.2005	JAYAGIRI	7	3203020007	JAYAGIRI	2
8	32.03.21.2002	MUARACIKA-DU	8	3203020008	MUARACIKA-DU	2
9	32.03.21.2007	GIRIMUKTI	9	3203020009	GIRIMUKTI	2
10	32.03.21.2010	MEKARLAK-SANA	10	3203020010	MEKARLAK-SANA	2
11	32.03.21.2011	KERTAMUKTI	11	3203020011	KERTAMUKTI	2

Catatan :
*) 1. Perkotaan
2. Perdesaan

https://jabar.bps.go.id

DAFTAR DESA/KELURAHAN

PROVINSI : [32] JAWA BARAT
KAB/KOTA : [03] CIANJUR
KECAMATAN : [030] CIDAUN

Data Kemendagri			MFD 2021 Semester 2			
No	Kode	Nama Desa	No	Kode	Nama Desa	Status*
1	32.03.23.2010	KARYABAKTI	1	3203030001	KARYABAKTI	2
2	32.03.23.2007	SUKAPURA	2	3203030002	SUKAPURA	2
3	32.03.23.2003	CISALAK	3	3203030003	CISALAK	2
4	32.03.23.2011	JAYAPURA	4	3203030004	JAYAPURA	2
5	32.03.23.2006	KERTAJADI	5	3203030005	KERTAJADI	2
6	32.03.23.2001	CIDAMAR	6	3203030006	CIDAMAR	2
7	32.03.23.2009	KARANG WANGI	7	3203030007	KARANG WANGI	2
8	32.03.23.2004	CIMARAGANG	8	3203030008	CIMARAGANG	2
9	32.03.23.2008	GELARPAWI-TAN	9	3203030009	GELARPAWI-TAN	2
10	32.03.23.2012	NEGLASARI	10	3203030010	NEGLASARI	2
11	32.03.23.2002	CIBULUH	11	3203030011	CIBULUH	2
12	32.03.23.2013	PUNCAKBARU	12	3203030012	PUNCAKBARU	2
13	32.03.23.2005	MEKARJAYA	13	3203030013	MEKARJAYA	2
14	32.03.23.2014	GELARWANGI	14	3203030014	GELARWANGI	2

Catatan :
*) 1. Perkotaan
2. Perdesaan

https://jabar.bps.go.id

PROVINSI : [32] JAWA BARAT
KAB/KOTA : [03] CIANJUR
KECAMATAN : [040] NARINGGUL

Data Kemendagri			MFD 2021 Semester 2			
No	Kode	Nama Desa	No	Kode	Nama Desa	Status*
1	32.03.24.2005	CINERANG	1	3203040001	CINERANG	2
2	32.03.24.2003	WANGUNJAYA	2	3203040002	WANGUNJAYA	2
3	32.03.24.2004	MEKARSARI	3	3203040003	MEKARSARI	2
4	32.03.24.2009	WANGUNSARI	4	3203040004	WANGUNSARI	2
5	32.03.24.2008	MALATI	5	3203040005	MALATI	2
6	32.03.24.2010	SUKAMULYA	6	3203040006	SUKAMULYA	2
7	32.03.24.2001	NARINGGUL	7	3203040007	NARINGGUL	2
8	32.03.24.2006	WANASARI	8	3203040008	WANASARI	2
9	32.03.24.2007	SUKABAKTI	9	3203040009	SUKABAKTI	2
10	32.03.24.2002	BALEGEDE	10	3203040010	BALEGEDE	2
11	32.03.24.2011	MARGASARI	11	3203040011	MARGASARI	2

Catatan :
*) 1. Perkotaan
2. Perdesaan

https://jabar.bps.go.id

DAFTAR DESA/KELURAHAN

PROVINSI : [32] JAWA BARAT
KAB/KOTA : [03] CIANJUR
KECAMATAN : [050] CIBINONG

Data Kemendagri			MFD 2021 Semester 2			
No	Kode	Nama Desa	No	Kode	Nama Desa	Status*
1	32.03.20.2004	PANYINDANGAN	1	3203050001	PANYINDANGAN	2
2	32.03.20.2012	WARGALUYU	2	3203050002	WARGALUYU	2
3	32.03.20.2010	HAMERANG	3	3203050003	HAMERANG	2
4	32.03.20.2001	PANANGGA-PAN	4	3203050004	PANANGGA-PAN	2
5	32.03.20.2011	GIRIJAYA	5	3203050005	GIRIJAYA	2
6	32.03.20.2003	SUKAJADI	6	3203050006	SUKAJADI	2
7	32.03.20.2009	SUKAMEKAR	7	3203050007	SUKAMEKAR	2
8	32.03.20.2008	BATULAWANG	8	3203050008	BATULAWANG	2
9	32.03.20.2002	CIKANG-KARENG	9	3203050009	CIKANG-KARENG	2
10	32.03.20.2007	PAMOYANAN	10	3203050015	PAMOYANAN	2
11	32.03.20.2006	CIMASKARA	11	3203050016	CIMASKARA	2
12	32.03.20.2005	PADASUKA	12	3203050020	PADASUKA	2
13	32.03.20.2013	MEKARMUKTI	13	3203050021	MEKARMUKTI	2
14	32.03.20.2014	CIBURIAL	14	3203050022	CIBURIAL	2

Catatan :
*) 1. Perkotaan
2. Perdesaan

https://jabar.bps.go.id

PROVINSI : [32] JAWA BARAT
KAB/KOTA : [03] CIANJUR
KECAMATAN : [051] CIKADU

Data Kemendagri			MFD 2021 Semester 2			
No	Kode	Nama Desa	No	Kode	Nama Desa	Status*
1	32.03.26.2004	PADALUYU	1	3203051001	PADALUYU	2
2	32.03.26.2008	SUKALUYU	2	3203051002	SUKALUYU	2
3	32.03.26.2007	MEKARLAK-SANA	3	3203051003	MEKARLAK-SANA	2
4	32.03.26.2002	CIKADU	4	3203051004	CIKADU	2
5	32.03.26.2001	KALAPANUNG-GAL	5	3203051005	KALAPANUNG-GAL	2
6	32.03.26.2003	MEKARWANGI	6	3203051006	MEKARWANGI	2
7	32.03.26.2006	CISARANTEN	7	3203051007	CISARANTEN	2
8	32.03.26.2005	SUKAMULYA	8	3203051008	SUKAMULYA	2
9	32.03.26.2009	MEKARJAYA	9	3203051009	MEKARJAYA	2
10	32.03.26.2010	SUKAMANAH	10	3203051010	SUKAMANAH	2

https://jabar.bps.go.id

Catatan :
*) 1. Perkotaan
2. Perdesaan

DAFTAR DESA/KELURAHAN

PROVINSI : [32] JAWA BARAT
KAB/KOTA : [03] CIANJUR
KECAMATAN : [060] TANGGEUNG

Data Kemendagri			MFD 2021 Semester 2			
No	Kode	Nama Desa	No	Kode	Nama Desa	Status*
1	32.03.19.2005	KARANG TENGAH	1	3203060001	KARANG TENGAH	2
2	32.03.19.2002	RAWAGEDE	2	3203060002	RAWAGEDE	2
3	32.03.19.2014	SUKAJAYA	3	3203060003	SUKAJAYA	2
4	32.03.19.2001	TANGGEUNG	4	3203060004	TANGGEUNG	1
5	32.03.19.2013	KERTAJAYA	5	3203060005	KERTAJAYA	2
6	32.03.19.2010	SIRNAJAYA	6	3203060006	SIRNAJAYA	2
7	32.03.19.2009	PASIR JAMBU	7	3203060007	PASIR JAMBU	2
8	32.03.19.2003	CILONGSONG	8	3203060008	CILONGSONG	2
9	32.03.19.2004	MARGALUYU	9	3203060009	MARGALUYU	2
10	32.03.19.2006	PAGER-MANEUH	10	3203060010	PAGER-MANEUH	2
11	32.03.19.2007	BOJONGPETIR	11	3203060011	BOJONGPETIR	2
12	32.03.19.2015	PADALUYU	12	3203060012	PADALUYU	2

Catatan :
*) 1. Perkotaan
2. Perdesaan

https://jabar.bps.go.id

PROVINSI : [32] JAWA BARAT
KAB/KOTA : [03] CIANJUR
KECAMATAN : [061] PASIRKUDA

Data Kemendagri			MFD 2021 Semester 2			
No	Kode	Nama Desa	No	Kode	Nama Desa	Status*
1	32.03.32.2007	MEKARMULYA	1	3203061001	MEKARMULYA	2
2	32.03.32.2004	KUBANG	2	3203061002	KUBANG	2
3	32.03.32.2008	GIRIJAYA	3	3203061003	GIRIJAYA	2
4	32.03.32.2005	GIRIMUKTI	4	3203061004	GIRIMUKTI	2
5	32.03.32.2001	SIMPANG	5	3203061005	SIMPANG	2
6	32.03.32.2002	KALIBARU	6	3203061006	KALIBARU	2
7	32.03.32.2003	PUSAKAJAYA	7	3203061007	PUSAKAJAYA	2
8	32.03.32.2006	KARANGJAYA	8	3203061008	KARANGJAYA	2
9	32.03.32.2009	PADAMULYA	9	3203061009	PADAMULYA	2

Catatan :
*) 1. Perkotaan
2. Perdesaan

https://jabar.bps.go.id

DAFTAR DESA/KELURAHAN

PROVINSI : [32] JAWA BARAT
KAB/KOTA : [03] CIANJUR
KECAMATAN : [070] KADUPANDAK

Data Kemendagri			MFD 2021 Semester 2			
No	Kode	Nama Desa	No	Kode	Nama Desa	Status*
1	32.03.17.2006	PASIRDALEM	1	3203070010	PASIRDALEM	2
2	32.03.17.2020	SUKARAJA	2	3203070011	SUKARAJA	2
3	32.03.17.2021	KADUPANDAK	3	3203070012	KADUPANDAK	1
4	32.03.17.2008	TALAGASARI	4	3203070013	TALAGASARI	2
5	32.03.17.2016	NEGLASARI	5	3203070014	NEGLASARI	2
6	32.03.17.2014	SUKAKERTA	6	3203070015	SUKAKERTA	2
7	32.03.17.2011	SUKARAHARJA	7	3203070016	SUKARAHARJA	2
8	32.03.17.2009	BOJONGKASIH	8	3203070017	BOJONGKASIH	2
9	32.03.17.2003	SUKASARI	9	3203070018	SUKASARI	2
10	32.03.17.2019	WARGASARI	10	3203070019	WARGASARI	2
11	32.03.17.2010	WARGAASIH	11	3203070020	WARGAASIH	2
12	32.03.17.2017	SUKARESMI	12	3203070021	SUKARESMI	2
13	32.03.17.2022	GANDASARI	13	3203070022	GANDASARI	2
14	32.03.17.2023	SINDANGSARI	14	3203070023	SINDANGSARI	2

Catatan :
*) 1. Perkotaan
2. Perdesaan

https://jabar.bps.go.id

PROVINSI : [32] JAWA BARAT
KAB/KOTA : [03] CIANJUR
KECAMATAN : [071] CIJATI

Data Kemendagri			MFD 2021 Semester 2			
No	Kode	Nama Desa	No	Kode	Nama Desa	Status*
1	32.03.29.2001	PADAASIH	1	3203071001	PADAASIH	2
2	32.03.29.2002	SUKALUYU	2	3203071002	SUKALUYU	2
3	32.03.29.2003	SINARBAKTI	3	3203071003	SINARBAKTI	2
4	32.03.29.2004	BOJONGLA-RANG	4	3203071004	BOJONGLA-RANG	2
5	32.03.29.2005	SUKAMAHI	5	3203071005	SUKAMAHI	2
6	32.03.29.2006	CIJATI	6	3203071006	CIJATI	2
7	32.03.29.2007	CIBODAS	7	3203071007	CIBODAS	2
8	32.03.29.2008	CARINGIN	8	3203071008	CARINGIN	2
9	32.03.29.2009	PARAKANTU-GU	9	3203071009	PARAKANTU-GU	2
10	32.03.29.2010	SUKAMAJU	10	3203071010	SUKAMAJU	2

Catatan :
*) 1. Perkotaan
2. Perdesaan

https://jabar.bps.go.id

DAFTAR DESA/KELURAHAN

PROVINSI : [32] JAWA BARAT
KAB/KOTA : [03] CIANJUR
KECAMATAN : [080] TAKOKAK

Data Kemendagri			MFD 2021 Semester 2			
No	Kode	Nama Desa	No	Kode	Nama Desa	Status*
1	32.03.16.2009	WARINGINSARI	1	3203080001	WARINGINSARI	2
2	32.03.16.2005	SUKAGALIH	2	3203080002	SUKAGALIH	2
3	32.03.16.2004	SIMPANG	3	3203080003	SIMPANG	2
4	32.03.16.2003	SINDANGHAYU	4	3203080004	SINDANGHAYU	2
5	32.03.16.2002	SINDANG RESMI	5	3203080005	SINDANG RESMI	2
6	32.03.16.2006	BUNGBANG-SARI	6	3203080006	BUNGBANG-SARI	2
7	32.03.16.2007	CISUJEN	7	3203080007	CISUJEN	2
8	32.03.16.2001	PASAWAHAN	8	3203080008	PASAWAHAN	2
9	32.03.16.2008	HEGARMANAH	9	3203080009	HEGARMANAH	2

https://jabar.bps.go.id

Catatan :
*) 1. Perkotaan
2. Perdesaan

PROVINSI : [32] JAWA BARAT
KAB/KOTA : [03] CIANJUR
KECAMATAN : [090] SUKANAGARA

Data Kemendagri			MFD 2021 Semester 2			
No	Kode	Nama Desa	No	Kode	Nama Desa	Status*
1	32.03.14.2010	JAYAGIRI	1	3203090001	JAYAGIRI	2
2	32.03.14.2004	CIGUHA	2	3203090002	CIGUHA	2
3	32.03.14.2003	SUKAKARYA	3	3203090003	SUKAKARYA	2
4	32.03.14.2008	SUKARAME	4	3203090004	SUKARAME	2
5	32.03.14.2007	SUKALAKSANA	5	3203090005	SUKALAKSANA	2
6	32.03.14.2001	SUKANAGARA	6	3203090006	SUKANAGARA	1
7	32.03.14.2006	GUNUNGSARI	7	3203090007	GUNUNGSARI	2
8	32.03.14.2009	SINDANGSARI	8	3203090008	SINDANGSARI	2
9	32.03.14.2002	SUKAJEMBAR	9	3203090009	SUKAJEMBAR	2
10	32.03.14.2005	SUKAMEKAR	10	3203090010	SUKAMEKAR	1

https://jabar.bps.go.id

Catatan :
*) 1. Perkotaan
2. Perdesaan

DAFTAR DESA/KELURAHAN

PROVINSI : [32] JAWA BARAT
KAB/KOTA : [03] CIANJUR
KECAMATAN : [100] PAGELARAN

Data Kemendagri			MFD 2021 Semester 2			
No	Kode	Nama Desa	No	Kode	Nama Desa	Status*
1	32.03.18.2012	KERTARA-HARJA	1	3203100001	KERTARA-HARJA	2
2	32.03.18.2001	PAGELARAN	2	3203100002	PAGELARAN	2
3	32.03.18.2014	PADAMAJU	3	3203100003	PADAMAJU	2
4	32.03.18.2005	BUNIWANGI	4	3203100008	BUNIWANGI	2
5	32.03.18.2009	BUNIJAYA	5	3203100009	BUNIJAYA	2
6	32.03.18.2002	PANGADEGAN	6	3203100010	PANGADEGAN	2
7	32.03.18.2010	SITUHIANG	7	3203100011	SITUHIANG	2
8	32.03.18.2008	PASIRBARU	8	3203100012	PASIRBARU	2
9	32.03.18.2007	SINDANGKER-TA	9	3203100013	SINDANGKER-TA	2
10	32.03.18.2015	KARANGHAR-JA	10	3203100014	KARANGHAR-JA	2
11	32.03.18.2013	SELAGEDANG	11	3203100015	SELAGEDANG	2
12	32.03.18.2004	GELAR ANYAR	12	3203100016	GELAR ANYAR	2
13	32.03.18.2011	MEKARSARI	13	3203100017	MEKARSARI	2
14	32.03.18.2018	SUKAMAJU	14	3203100018	SUKAMAJU	2

Catatan :
*) 1. Perkotaan
2. Perdesaan

https://jabar.bps.go.id

PROVINSI : [32] JAWA BARAT
KAB/KOTA : [03] CIANJUR
KECAMATAN : [110] CAMPAKA

Data Kemendagri			MFD 2021 Semester 2			
No	Kode	Nama Desa	No	Kode	Nama Desa	Status*
1	32.03.15.2009	WANGUNJAYA	1	3203110001	WANGUNJAYA	2
2	32.03.15.2005	SUKADANA	2	3203110002	SUKADANA	2
3	32.03.15.2007	KARYAMUKTI	3	3203110003	KARYAMUKTI	2
4	32.03.15.2002	CIMENTENG	4	3203110004	CIMENTENG	2
5	32.03.15.2010	GIRIMUKTI	5	3203110005	GIRIMUKTI	2
6	32.03.15.2003	SUSUKAN	6	3203110006	SUSUKAN	2
7	32.03.15.2004	SUKAJADI	7	3203110007	SUKAJADI	1
8	32.03.15.2006	MARGALUYU	8	3203110008	MARGALUYU	2
9	32.03.15.2011	MEKARJAYA	9	3203110009	MEKARJAYA	2
10	32.03.15.2001	CIDADAP	10	3203110010	CIDADAP	2
11	32.03.15.2008	CAMPAKA	11	3203110011	CAMPAKA	2

Catatan :
*) 1. Perkotaan
2. Perdesaan

https://jabar.bps.go.id

DAFTAR DESA/KELURAHAN

PROVINSI : [32] JAWA BARAT
KAB/KOTA : [03] CIANJUR
KECAMATAN : [111] CAMPAKAMULYA

Data Kemendagri			MFD 2021 Semester 2			
No	Kode	Nama Desa	No	Kode	Nama Desa	Status*
1	32.03.25.2002	CAMPA-KAWARNA	1	3203111001	CAMPA-KAWARNA	2
2	32.03.25.2004	CAMPAKA MULYA	2	3203111002	CAMPAKA MULYA	2
3	32.03.25.2005	SUKABUNGAH	3	3203111003	SUKABUNGAH	2
4	32.03.25.2001	CIBANGGALA	4	3203111004	CIBANGGALA	2
5	32.03.25.2003	SUKASIRNA	5	3203111005	SUKASIRNA	2

Catatan :
*) 1. Perkotaan
2. Perdesaan

https://jabar.bps.go.id

PROVINSI : [32] JAWA BARAT
KAB/KOTA : [03] CIANJUR
KECAMATAN : [120] CIBEBER

Data Kemendagri			MFD 2021 Semester 2			
No	Kode	Nama Desa	No	Kode	Nama Desa	Status*
1	32.03.03.2009	CIBOKOR	1	3203120001	CIBOKOR	1
2	32.03.03.2012	KANOMAN	2	3203120002	KANOMAN	2
3	32.03.03.2001	CIPETIR	3	3203120003	CIPETIR	1
4	32.03.03.2008	CIKONDANG	4	3203120004	CIKONDANG	1
5	32.03.03.2002	CIHAUR	5	3203120005	CIHAUR	1
6	32.03.03.2017	SUKAMANAH	6	3203120006	SUKAMANAH	1
7	32.03.03.2010	SALAGEDANG	7	3203120007	SELAGEDANG	2
8	32.03.03.2016	CIBADAK	8	3203120008	CIBADAK	2
9	32.03.03.2014	GIRIMULYA	9	3203120009	GIRIMULYA	2
10	32.03.03.2003	CIMANGGU	10	3203120010	CIMANGGU	2
11	32.03.03.2015	CISALAK	11	3203120011	CISALAK	1
12	32.03.03.2007	MAYAK	12	3203120012	MAYAK	2
13	32.03.03.2006	PEUTEUY CONDONG	13	3203120013	PEUTEUY CONDONG	2
14	32.03.03.2005	SUKARAHARJA	14	3203120014	SUKARAHARJA	2
15	32.03.03.2013	SUKAMAJU	15	3203120015	SUKAMAJU	2
16	32.03.03.2004	CIBAREGBEG	16	3203120016	CIBAREGBEG	2
17	32.03.03.2011	KARANG-NUNGGAL	17	3203120017	KARANG-NUNGGAL	2
18	32.03.03.2018	SALAMNUNG-GAL	18	3203120018	SALAMNUNG-GAL	2

Catatan :
*) 1. Perkotaan
2. Perdesaan

https://jabar.bps.go.id

DAFTAR DESA/KELURAHAN

PROVINSI : [32] JAWA BARAT
KAB/KOTA : [03] CIANJUR
KECAMATAN : [130] WARUNGKONDANG

Data Kemendagri			MFD 2021 Semester 2			
No	Kode	Nama Desa	No	Kode	Nama Desa	Status*
1	32.03.02.2006	CISARANDI	1	3203130002	CISARANDI	2
2	32.03.02.2016	SUKAMULYA	2	3203130003	SUKAMULYA	2
3	32.03.02.2007	CIKAROYA	3	3203130004	CIKAROYA	1
4	32.03.02.2002	JAMBUDIPA	4	3203130012	JAMBUDIPA	1
5	32.03.02.2018	MEKARWANGI	5	3203130013	MEKARWANGI	2
6	32.03.02.2010	TEGALLEGA	6	3203130014	TEGALLEGA	2
7	32.03.02.2008	BUNIKASIH	7	3203130015	BUNIKASIH	2
8	32.03.02.2014	BUNISARI	8	3203130016	BUNISARI	2
9	32.03.02.2017	CIEUNDEUR	9	3203130017	CIEUNDEUR	1
10	32.03.02.2009	CIWALEN	10	3203130018	CIWALEN	2
11	32.03.02.2011	SUKAWANGI	11	3203130019	SUKAWANGI	2

Catatan :
*) 1. Perkotaan
2. Perdesaan

https://jabar.bps.go.id

PROVINSI : [32] JAWA BARAT
KAB/KOTA : [03] CIANJUR
KECAMATAN : [131] GEKBRONG

Data Kemendagri			MFD 2021 Semester 2			
No	Kode	Nama Desa	No	Kode	Nama Desa	Status*
1	32.03.27.2008	CINTAASIH	1	3203131001	CINTAASIH	2
2	32.03.27.2004	CIKANCANA	2	3203131002	CIKANCANA	2
3	32.03.27.2003	SUKARATU	3	3203131003	SUKARATU	2
4	32.03.27.2001	BANGBAYANG	4	3203131004	BANGBAYANG	2
5	32.03.27.2002	SONGGOM	5	3203131005	SONGGOM	2
6	32.03.27.2007	CIKAHURIPAN	6	3203131006	CIKAHURIPAN	2
7	32.03.27.2006	GEKBRONG	7	3203131007	GEKBRONG	2
8	32.03.27.2005	KEBONPEU-TEUY	8	3203131008	KEBONPEU-TEUY	2

Catatan :
*) 1. Perkotaan
2. Perdesaan

https://jabar.bps.go.id

DAFTAR DESA/KELURAHAN

PROVINSI : [32] JAWA BARAT
KAB/KOTA : [03] CIANJUR
KECAMATAN : [140] CILAKU

Data Kemendagri			MFD 2021 Semester 2			
No	Kode	Nama Desa	No	Kode	Nama Desa	Status*
1	32.03.04.2002	SUKASARI	1	3203140001	SUKASARI	2
2	32.03.04.2004	SUKAKERTA	2	3203140002	SUKAKERTA	2
3	32.03.04.2008	SINDANGSARI	3	3203140003	SINDANGSARI	2
4	32.03.04.2010	MULYASARI	4	3203140004	MULYASARI	2
5	32.03.04.2009	CIHARASHAS	5	3203140005	CIHARASHAS	2
6	32.03.04.2005	CIBINONG HILIR	6	3203140006	CIBINONG HILIR	2
7	32.03.04.2003	SIRNAGALIH	7	3203140007	SIRNAGALIH	1
8	32.03.04.2006	RAHONG	8	3203140008	RAHONG	2
9	32.03.04.2007	MUNJUL	9	3203140009	MUNJUL	2
10	32.03.04.2001	RANCAGOONG	10	3203140010	RANCAGOONG	1

Catatan :
*) 1. Perkotaan
2. Perdesaan

https://jabar.bps.go.id

PROVINSI : [32] JAWA BARAT
KAB/KOTA : [03] CIANJUR
KECAMATAN : [150] SUKALUYU

Data Kemendagri			MFD 2021 Semester 2			
No	Kode	Nama Desa	No	Kode	Nama Desa	Status*
1	32.03.09.2006	MEKARJAYA	1	3203150001	MEKARJAYA	2
2	32.03.09.2003	PANYUSUHAN	2	3203150002	PANYUSUHAN	2
3	32.03.09.2008	SUKALUYU	3	3203150003	SUKALUYU	2
4	32.03.09.2002	SUKAMULYA	4	3203150004	SUKAMULYA	1
5	32.03.09.2009	BABAKANSARI	5	3203150005	BABAKANSARI	1
6	32.03.09.2004	TANJUNGSARI	6	3203150006	TANJUNGSARI	2
7	32.03.09.2001	SELAJAMBE	7	3203150007	SELAJAMBE	2
8	32.03.09.2010	HEGARMANAH	8	3203150008	HEGARMANAH	1
9	32.03.09.2007	SUKASIRNA	9	3203150009	SUKASIRNA	2
10	32.03.09.2005	SINDANGRAJA	10	3203150010	SINDANGRAJA	2

https://jabar.bps.go.id

Catatan :
*) 1. Perkotaan
2. Perdesaan

DAFTAR DESA/KELURAHAN

PROVINSI : [32] JAWA BARAT
KAB/KOTA : [03] CIANJUR
KECAMATAN : [160] BOJONGPICUNG

Data Kemendagri			MFD 2021 Semester 2			
No	Kode	Nama Desa	No	Kode	Nama Desa	Status*
1	32.03.06.2010	SUKARAMA	1	3203160001	SUKARAMA	2
2	32.03.06.2007	SUKAJAYA	2	3203160002	SUKAJAYA	2
3	32.03.06.2009	CIKONDANG	3	3203160003	CIKONDANG	2
4	32.03.06.2014	JATISARI	4	3203160004	JATISARI	2
5	32.03.06.2006	KEMANG	5	3203160005	KEMANG	2
6	32.03.06.2004	CIBARENGKOK	6	3203160006	CIBARENGKOK	2
7	32.03.06.2008	JATI	7	3203160007	JATI	2
8	32.03.06.2002	BOJONGPI-CUNG	8	3203160008	BOJONGPI-CUNG	1
9	32.03.06.2012	SUKARATU	9	3203160009	SUKARATU	2
10	32.03.06.2013	NEGLASARI	10	3203160012	NEGLASARI	1
11	32.03.06.2001	HEGARMANAH	11	3203160013	HEGARMANAH	1

Catatan :
*) 1. Perkotaan
2. Perdesaan

https://jabar.bps.go.id

PROVINSI : [32] JAWA BARAT
KAB/KOTA : [03] CIANJUR
KECAMATAN : [161] HAURWANGI

Data Kemendagri			MFD 2021 Semester 2			
No	Kode	Nama Desa	No	Kode	Nama Desa	Status*
1	32.03.31.2002	CIHEA	1	3203161001	CIHEA	2
2	32.03.31.2004	SUKATANI	2	3203161002	SUKATANI	2
3	32.03.31.2003	RAMASARI	3	3203161003	RAMASARI	2
4	32.03.31.2001	HAURWANGI	4	3203161004	HAURWANGI	1
5	32.03.31.2006	KERTASARI	5	3203161005	KERTASARI	2
6	32.03.31.2008	KERTAMUKTI	6	3203161006	KERTAMUKTI	2
7	32.03.31.2007	CIPEUYEUM	7	3203161007	CIPEUYEUM	2
8	32.03.31.2005	MEKARWANGI	8	3203161008	MEKARWANGI	1

Catatan :
*) 1. Perkotaan
2. Perdesaan

https://jabar.bps.go.id

DAFTAR DESA/KELURAHAN

PROVINSI : [32] JAWA BARAT
KAB/KOTA : [03] CIANJUR
KECAMATAN : [170] CIRANJANG

Data Kemendagri			MFD 2021 Semester 2			
No	Kode	Nama Desa	No	Kode	Nama Desa	Status*
1	32.03.05.2006	KARANG WANGI	1	3203170004	KARANG WANGI	1
2	32.03.05.2005	GUNUNGSARI	2	3203170005	GUNUNGSARI	1
3	32.03.05.2008	KERTAJAYA	3	3203170006	KERTAJAYA	2
4	32.03.05.2002	SINDANGJAYA	4	3203170007	SINDANGJAYA	2
5	32.03.05.2009	SINDANGSARI	5	3203170008	SINDANGSARI	2
6	32.03.05.2004	CIBIUK	6	3203170009	CIBIUK	1
7	32.03.05.2012	MEKARGALIH	7	3203170010	MEKARGALIH	1
8	32.03.05.2001	CIRANJANG	8	3203170011	CIRANJANG	1
9	32.03.05.2007	NANGGALA-MEKAR	9	3203170012	NANGGALA-MEKAR	2

Catatan :
*) 1. Perkotaan
2. Perdesaan

https://jabar.bps.go.id

PROVINSI : [32] JAWA BARAT
KAB/KOTA : [03] CIANJUR
KECAMATAN : [180] MANDE

Data Kemendagri			MFD 2021 Semester 2			
No	Kode	Nama Desa	No	Kode	Nama Desa	Status*
1	32.03.08.2010	MEKARJAYA	1	3203180001	MEKARJAYA	2
2	32.03.08.2009	LEUWIKOJA	2	3203180002	LEUWIKOJA	2
3	32.03.08.2011	KUTAWARING IN	3	3203180003	KUTAWARING IN	2
4	32.03.08.2008	SUKAMANAH	4	3203180004	SUKAMANAH	2
5	32.03.08.2007	CIANDAM	5	3203180005	CIANDAM	2
6	32.03.08.2003	JAMALI	6	3203180006	JAMALI	2
7	32.03.08.2001	KADEMANGAN	7	3203180007	KADEMANGAN	1
8	32.03.08.2006	MULYASARI	8	3203180008	MULYASARI	2
9	32.03.08.2002	BOBOJONG	9	3203180009	BOBOJONG	2
10	32.03.08.2004	CIKIDANGBAYA BANG	10	3203180010	CIKIDANGBAYA BANG	1
11	32.03.08.2012	MURNISARI	11	3203180011	MURNISARI	2
12	32.03.08.2005	MANDE	12	3203180012	MANDE	2

Catatan :
*) 1. Perkotaan
2. Perdesaan

https://jabar.bps.go.id

DAFTAR DESA/KELURAHAN

PROVINSI : [32] JAWA BARAT
KAB/KOTA : [03] CIANJUR
KECAMATAN : [180] KARANGTENGAH

Data Kemendagri			MFD 2021 Semester 2			
No	Kode	Nama Desa	No	Kode	Nama Desa	Status*
1	32.03.07.2001	SUKAMANAH	1	3203190001	SUKAMANAH	1
2	32.03.07.2011	SINDANGASIH	2	3203190002	SINDANGASIH	2
3	32.03.07.2013	LANGENSARI	3	3203190003	LANGENSARI	2
4	32.03.07.2008	SUKASARI	4	3203190004	SUKASARI	1
5	32.03.07.2004	MALEBER	5	3203190005	MALEBER	1
6	32.03.07.2010	SABANDAR	6	3203190006	SABANDAR	1
7	32.03.07.2002	BOJONG	7	3203190007	BOJONG	1
8	32.03.07.2014	HEGARMANAH	8	3203190008	HEGARMANAH	1
9	32.03.07.2009	BABAKANCA RINGIN	9	3203190009	BABAKANCA RINGIN	1
10	32.03.07.2005	CIHERANG	10	3203190010	CIHERANG	1
11	32.03.07.2015	SUKAJADI	11	3203190011	SUKAJADI	2
12	32.03.07.2007	SUKASARANA	12	3203190012	SUKASARANA	1
13	32.03.07.2006	SUKAMANTRI	13	3203190013	SUKAMANTRI	2
14	32.03.07.2016	SUKAMULYA	14	3203190014	SUKAMULYA	2
15	32.03.07.2003	SINDANGLAKA	15	3203190015	SINDANGLAKA	1
16	32.03.07.2012	SUKATARIS	16	3203190016	SUKATARIS	1

Catatan :
*) 1. Perkotaan
2. Perdesaan

https://jabar.bps.go.id

PROVINSI : [32] JAWA BARAT
KAB/KOTA : [03] CIANJUR
KECAMATAN : [200] CIANJUR

Data Kemendagri			MFD 2021 Semester 2			
No	Kode	Nama Desa	No	Kode	Nama Desa	Status*
1	32.03.01.2002	NAGRAK	1	3203200001	NAGRAK	1
2	32.03.01.2003	SUKAMAJU	2	3203200002	SUKAMAJU	1
3	32.03.01.1009	SAYANG	3	3203200003	SAYANG	1
4	32.03.01.1010	SOLOKPAN-DAN	4	3203200004	SOLOKPAN-DAN	1
5	32.03.01.1011	MUKA	5	3203200005	MUKA	1
6	32.03.01.1008	BOJONG-HERANG	6	3203200006	BOJONG-HERANG	1
7	32.03.01.1006	PAMOYANAN	7	3203200007	PAMOYANAN	1
8	32.03.01.1007	SAWAH GEDE	8	3203200008	SAWAH GEDE	1
9	32.03.01.2005	LIMBANGAN SARI	9	3203200009	LIMBANGAN-SARI	1
10	32.03.01.2004	MEKARSARI	10	3203200010	MEKARSARI	1
11	32.03.01.2001	BABAKAN-KARET	11	3203200011	BABAKAN-KARET	2

Catatan :
*) 1. Perkotaan
2. Perdesaan

https://jabar.bps.go.id

DAFTAR DESA/KELURAHAN

PROVINSI : [32] JAWA BARAT
KAB/KOTA : [03] CIANJUR
KECAMATAN : [210] CUGENANG

Data Kemendagri			MFD 2021 Semester 2			
No	Kode	Nama Desa	No	Kode	Nama Desa	Status*
1	32.03.11.2015	PADALUYU	1	3203210001	PADALUYU	2
2	32.03.11.2009	SUKAJAYA	2	3203210002	SUKAJAYA	2
3	32.03.11.2010	CIBULAKAN	3	3203210003	CIBULAKAN	2
4	32.03.11.2014	CIRUMPUT	4	3203210004	CIRUMPUT	2
5	32.03.11.2008	TALAGA	5	3203210005	TALAGA	2
6	32.03.11.2011	BENJOT	6	3203210006	BENJOT	2
7	32.03.11.2002	GASOL	7	3203210007	GASOL	2
8	32.03.11.2007	SARAMPAD	8	3203210008	SARAMPAD	2
9	32.03.11.2006	MANGUNKER-TA	9	3203210009	MANGUNKER-TA	2
10	32.03.11.2012	SUKAMULYA	10	3203210010	SUKAMULYA	2
11	32.03.11.2016	GALUDRA	11	3203210011	GALUDRA	2
12	32.03.11.2005	NYALINDUNG	12	3203210012	NYALINDUNG	1
13	32.03.11.2004	CIBEUREUM	13	3203210013	CIBEUREUM	2
14	32.03.11.2003	CIJEDIL	14	3203210014	CIJEDIL	2
15	32.03.11.2001	SUKAMANAH	15	3203210015	SUKAMANAH	2
16	32.03.11.2013	WANGUNJAYA	16	3203210016	WANGUNJAYA	2

Catatan :
*) 1. Perkotaan
2. Perdesaan

https://jabar.bps.go.id

PROVINSI : [32] JAWA BARAT
KAB/KOTA : [03] CIANJUR
KECAMATAN : [220] PACET

Data Kemendagri			MFD 2021 Semester 2			
No	Kode	Nama Desa	No	Kode	Nama Desa	Status*
1	32.03.10.2010	CIPUTRI	1	3203220001	CIPUTRI	2
2	32.03.10.2001	CIHERANG	2	3203220002	CIHERANG	1
3	32.03.10.2007	CIPENDAWA	3	3203220003	CIPENDAWA	1
4	32.03.10.2003	CIBODAS	4	3203220004	CIBODAS	2
5	32.03.10.2012	GADOG	5	3203220005	GADOG	1
6	32.03.10.2013	SUKATANI	6	3203220008	SUKATANI	1
7	32.03.10.2005	SUKANAGALIH	7	3203220014	SUKANAGALIH	1

Catatan :
*) 1. Perkotaan
2. Perdesaan

https://jabar.bps.go.id

DAFTAR DESA/KELURAHAN

PROVINSI : [32] JAWA BARAT
KAB/KOTA : [03] CIANJUR
KECAMATAN : [221] CIPANAS

Data Kemendagri			MFD 2021 Semester 2			
No	Kode	Nama Desa	No	Kode	Nama Desa	Status*
1	32.03.28.2007	SINDANGJAYA	1	3203221001	SINDANGJAYA	1
2	32.03.28.2001	CIPANAS	2	3203221002	CIPANAS	1
3	32.03.28.2004	SINDANGLAYA	3	3203221003	SINDANGLAYA	1
4	32.03.28.2006	PALASARI	4	3203221004	PALASARI	1
5	32.03.28.2002	CIMACAN	5	3203221005	CIMACAN	1
6	32.03.28.2003	CILOTO	6	3203221006	CILOTO	1
7	32.03.28.2005	BATULAWANG	7	3203221007	BATULAWANG	1

Catatan :
*) 1. Perkotaan
2. Perdesaan

https://jabar.bps.go.id

PROVINSI : [32] JAWA BARAT
KAB/KOTA : [03] CIANJUR
KECAMATAN : [230] SUKARESMI

Data Kemendagri			MFD 2021 Semester 2			
No	Kode	Nama Desa	No	Kode	Nama Desa	Status*
1	32.03.13.2010	PAKUON	1	3203230001	PAKUON	2
2	32.03.13.2001	CIKANYERE	2	3203230002	CIKANYERE	2
3	32.03.13.2007	SUKARESMI	3	3203230003	SUKARESMI	2
4	32.03.13.2003	CIWALEN	4	3203230004	CIWALEN	1
5	32.03.13.2004	KAWUNGLU-WUK	5	3203230005	KAWUNGLU-WUK	1
6	32.03.13.2005	CIBADAK	6	3203230006	CIBADAK	1
7	32.03.13.2011	RAWABELUT	7	3203230007	RAWABELUT	2
8	32.03.13.2008	CIBANTENG	8	3203230008	CIBANTENG	2
9	32.03.13.2009	KUBANG	9	3203230009	KUBANG	2
10	32.03.13.2006	SUKAMAHI	10	3203230010	SUKAMAHI	2
11	32.03.13.2002	CIKANCANA	11	3203230011	CIKANCANA	2

Catatan :
*) 1. Perkotaan
2. Perdesaan

https://jabar.bps.go.id

DAFTAR DESA/KELURAHAN

PROVINSI : [32] JAWA BARAT
KAB/KOTA : [03] CIANJUR
KECAMATAN : [240] CIKALONGKULON

Data Kemendagri			MFD 2021 Semester 2			
No	Kode	Nama Desa	No	Kode	Nama Desa	Status*
1	32.03.12.2011	PADAJAYA	1	3203240001	PADAJAYA	2
2	32.03.12.2003	CINANGSI	2	3203240002	CINANGSI	1
3	32.03.12.2016	MENTENGSARI	3	3203240003	MENTENGSARI	2
4	32.03.12.2002	GUDANG	4	3203240004	GUDANG	1
5	32.03.12.2001	SUKAGALIH	5	3203240005	SUKAGALIH	1
6	32.03.12.2005	MAJALAYA	6	3203240006	MAJALAYA	2
7	32.03.12.2004	CIJAGANG	7	3203240007	CIJAGANG	2
8	32.03.12.2009	MEKARJAYA	8	3203240008	MEKARJAYA	2
9	32.03.12.2017	MEKARSARI	9	3203240009	MEKARSARI	2
10	32.03.12.2010	SUKAMULYA	10	3203240010	SUKAMULYA	2
11	32.03.12.2014	MEKARGALIH	11	3203240011	MEKARGALIH	2
12	32.03.12.2013	NEGLASARI	12	3203240012	NEGLASARI	1
13	32.03.12.2015	LEMBAHSARI	13	3203240013	LEMBAHSARI	1
14	32.03.12.2007	WARUDOYONG	14	3203240014	WARUDOYONG	2
15	32.03.12.2006	KAMURANG	15	3203240015	KAMURANG	2
16	32.03.12.2008	CIRAMAGI-RANG	16	3203240016	CIRAMAGI-RANG	2
17	32.03.12.2018	MEKAR MULYA	17	3203240017	MEKARMULYA	2
18	32.03.12.2012	CIGUNUNG-HERANG	18	3203240018	CIGUNUNG-HERANG	2

Catatan :
*) 1. Perkotaan
2. Perdesaan

https://jabar.bps.go.id

KABUPATEN BANDUNG

https://jabar.bps.go.id

https://jabar.bps.go.id

PROVINSI : [32] JAWA BARAT
KAB/KOTA : [04] BANDUNG

Data Kemendagri			MFD 2021 Semester 2		
No	Kode	Nama Kecamatan	No	Kode	Nama Kecamatan
1	32.04.39	CIWIDEY	1	3204010	CIWIDEY
2	32.04.40	RANCABALI	2	3204011	RANCABALI
3	32.04.38	PASIRJAMBU	3	3204020	PASIRJAMBU
4	32.04.17	CIMAUNG	4	3204030	CIMAUNG
5	32.04.15	PANGALENGAN	5	3204040	PANGALENGAN
6	32.04.31	KERTASARI	6	3204050	KERTASARI
7	32.04.30	PACET	7	3204060	PACET
8	32.04.36	IBUN	8	3204070	IBUN
9	32.04.35	PASEH	9	3204080	PASEH
10	32.04.27	CIKANCUNG	10	3204090	CIKANCUNG
11	32.04.25	CICALENGKA	11	3204100	CICALENGKA
12	32.04.26	NAGREG	12	3204101	NAGREG
13	32.04.28	RANCAEKEK	13	3204110	RANCAEKEK
14	32.04.33	MAJALAYA	14	3204120	MAJALAYA
15	32.04.34	SOLOKAN JERUK	15	3204121	SOLOKAN JERUK
16	32.04.29	CIPARAY	16	3204130	CIPARAY
17	32.04.32	BALEENDAH	17	3204140	BALEENDAH
18	32.04.16	ARJASARI	18	3204150	ARJASARI
19	32.04.13	BANJARAN	19	3204160	BANJARAN
20	32.04.44	CANGKUANG	20	3204161	CANGKUANG
21	32.04.14	PAMEUNGPEUK	21	3204170	PAMEUNGPEUK
22	32.04.11	KATAPANG	22	3204180	KATAPANG

https://jabar.bps.go.id

DAFTAR KECAMATAN

PROVINSI : [32] JAWA BARAT
KAB/KOTA : [04] BANDUNG

Data Kemendagri			MFD 2021 Semester 2		
No	Kode	Nama Kecamatan	No	Kode	Nama Kecamatan
23	32.04.37	SOREANG	23	3204190	SOREANG
24	32.04.46	KUTAWARINGIN	24	3204191	KUTAWARINGIN
25	32.04.10	MARGAASIH	25	3204250	MARGAASIH
26	32.04.09	MARGAHAYU	26	3204260	MARGAHAYU
27	32.04.12	DAYEUHKOLOT	27	3204270	DAYEUHKOLOT
28	32.04.08	BOJONGSOANG	28	3204280	BOJONGSOANG
29	32.04.05	CILEUNYI	29	3204290	CILEUNYI
30	32.04.07	CILENGKRANG	30	3204300	CILENGKRANG
31	32.04.06	CIMENYAN	31	3204310	CIMENYAN

Catatan :
*) 1. Perkotaan
2. Perdesaan

https://jabar.bps.go.id

JUMLAH DESA/KELURAHAN PER KECAMATAN

PROVINSI : [32] JAWA BARAT
KAB/KOTA : [04] BANDUNG

Data Kemendagri				MFD 2021 Semester 2			
No	Kode	Nama Kecamatan	Jml Desa	No	Kode	Nama Kecamatan	Jml Desa
1	32.04.39	CIWIDEY	7	1	3204010	CIWIDEY	7
2	32.04.40	RANCABALI	5	2	3204011	RANCABALI	5
3	32.04.38	PASIRJAMBU	10	3	3204020	PASIRJAMBU	10
4	32.04.17	CIMAUNG	10	4	3204030	CIMAUNG	10
5	32.04.15	PANGALENGAN	13	5	3204040	PANGALENGAN	13
6	32.04.31	KERTASARI	8	6	3204050	KERTASARI	8
7	32.04.30	PACET	13	7	3204060	PACET	13
8	32.04.36	IBUN	12	8	3204070	IBUN	12
9	32.04.35	PASEH	12	9	3204080	PASEH	12
10	32.04.27	CIKANCUNG	9	10	3204090	CIKANCUNG	9
11	32.04.25	CICALENGKA	12	11	3204100	CICALENGKA	12
12	32.04.26	NAGREG	8	12	3204101	NAGREG	8
13	32.04.28	RANCAEKEK	14	13	3204110	RANCAEKEK	14
14	32.04.33	MAJALAYA	11	14	3204120	MAJALAYA	11
15	32.04.34	SOLOKAN JERUK	7	15	3204121	SOLOKAN JERUK	7
16	32.04.29	CIPARAY	14	16	3204130	CIPARAY	14
17	32.04.32	BALEENDAH	8	17	3204140	BALEENDAH	8
18	32.04.16	ARJASARI	11	18	3204150	ARJASARI	11
19	32.04.13	BANJARAN	11	19	3204160	BANJARAN	11
20	32.04.44	CANGKUANG	7	20	3204161	CANGKUANG	7
21	32.04.14	PAMEUNGPEUK	6	21	3204170	PAMEUNGPEUK	6

https://jabar.bps.go.id

JUMLAH DESA/KELURAHAN PER KECAMATAN

PROVINSI : [32] JAWA BARAT
KAB/KOTA : [04] BANDUNG

Data Kemendagri				MFD 2021 Semester 2			
No	Kode	Nama Kecamatan	Jml Desa	No	Kode	Nama Kecamatan	Jml Desa
22	32.04.11	KATAPANG	7	22	3204180	KATAPANG	7
23	32.04.37	SOREANG	10	23	3204190	SOREANG	10
24	32.04.46	KUTAWARINGIN	11	24	3204191	KUTAWARINGIN	11
25	32.04.10	MARGAASIH	6	25	3204250	MARGAASIH	6
26	32.04.09	MARGAHAYU	5	26	3204260	MARGAHAYU	5
27	32.04.12	DAYEUHKOLOT	6	27	3204270	DAYEUHKOLOT	6
28	32.04.08	BOJONGSOANG	6	28	3204280	BOJONGSOANG	6
29	32.04.05	CILEUNYI	6	29	3204290	CILEUNYI	6
30	32.04.07	CILENGKRANG	6	30	3204300	CILENGKRANG	6
31	32.04.06	CIMENYAN	9	31	3204310	CIMENYAN	9

https://jabar.bps.go.id

PROVINSI : [32] JAWA BARAT
KAB/KOTA : [04] BANDUNG
KECAMATAN : [010] CIWIDEY

Data Kemendagri			MFD 2021 Semester 2			
No	Kode	Nama Desa	No	Kode	Nama Desa	Status*
1	32.04.39.2004	PANUNDAAN	1	3204010001	PANUNDAAN	2
2	32.04.39.2002	CIWIDEY	2	3204010002	CIWIDEY	1
3	32.04.39.2005	PANYOCOKAN	3	3204010003	PANYOCOKAN	1
4	32.04.39.2001	LEBAKMUN-CANG	4	3204010004	LEBAKMUN-CANG	2
5	32.04.39.2006	RAWABOGO	5	3204010005	RAWABOGO	2
6	32.04.39.2003	NENGKELAN	6	3204010006	NENGKELAN	2
7	32.04.39.2007	SUKAWENING	7	3204010007	SUKAWENING	2

Catatan :
*) 1. Perkotaan
2. Perdesaan

https://jabar.bps.go.id

DAFTAR DESA/KELURAHAN

PROVINSI : [32] JAWA BARAT
KAB/KOTA : [04] BANDUNG
KECAMATAN : [011] RANCABALI

Data Kemendagri			MFD 2021 Semester 2			
No	Kode	Nama Desa	No	Kode	Nama Desa	Status*
1	32.04.40.2004	CIPELAH	1	3204011001	CIPELAH	1
2	32.04.40.2002	SUKARESMI	2	3204011002	SUKARESMI	1
3	32.04.40.2003	INDRAGIRI	3	3204011003	INDRAGIRI	1
4	32.04.40.2001	PATENGAN	4	3204011004	PATENGAN	1
5	32.04.40.2005	ALAMENDAH	5	3204011005	ALAMENDAH	1

Catatan :
*) 1. Perkotaan
2. Perdesaan

https://jabar.bps.go.id

PROVINSI : [32] JAWA BARAT
KAB/KOTA : [04] BANDUNG
KECAMATAN : [020] PASIRJAMBU

Data Kemendagri			MFD 2021 Semester 2			
No	Kode	Nama Desa	No	Kode	Nama Desa	Status*
1	32.04.38.2009	SUGIHMUKTI	1	3204020001	SUGIHMUKTI	2
2	32.04.38.2006	MARGAMULYA	2	3204020002	MARGAMULYA	1
3	32.04.38.2010	TENJOLAYA	3	3204020003	TENJOLAYA	1
4	32.04.38.2005	CISONDARI	4	3204020004	CISONDARI	2
5	32.04.38.2007	MEKARSARI	5	3204020005	MEKARSARI	1
6	32.04.38.2002	CIBODAS	6	3204020006	CIBODAS	1
7	32.04.38.2004	CUKANGGEN-TENG	7	3204020007	CUKANGGEN-TENG	1
8	32.04.38.2001	PASIRJAMBU	8	3204020008	PASIRJAMBU	1
9	32.04.38.2009	MEKARMAJU	9	3204020009	MEKARMAJU	1
10	32.04.38.2003	CIKONENG	10	3204020010	CIKONENG	1

Catatan :
*) 1. Perkotaan
2. Perdesaan

https://jabar.bps.go.id

DAFTAR DESA/KELURAHAN

PROVINSI : [32] JAWA BARAT
KAB/KOTA : [04] BANDUNG
KECAMATAN : [030] CIMAUNG

Data Kemendagri			MFD 2021 Semester 2			
No	Kode	Nama Desa	No	Kode	Nama Desa	Status*
1	32.04.17.2008	CIKALONG	1	3204030001	CIKALONG	1
2	32.04.17.2006	MEKARSARI	2	3204030002	MEKARSARI	1
3	32.04.17.2005	CIPINANG	3	3204030003	CIPINANG	1
4	32.04.17.2001	CIMAUNG	4	3204030004	CIMAUNG	1
5	32.04.17.2004	CAMPAKA MULYA	5	3204030005	CAMPAKA MULYA	2
6	32.04.17.2003	PASIRHUNI	6	3204030006	PASIRHUNI	2
7	32.04.17.2002	JAGABAYA	7	3204030007	JAGABAYA	1
8	32.04.17.2009	MALASARI	8	3204030008	MALASARI	2
9	32.04.17.2007	SUKAMAJU	9	3204030009	SUKAMAJU	2
10	32.04.17.2010	WARJABAKTI	10	3204030010	WARJABAKTI	1

Catatan :
*) 1. Perkotaan
2. Perdesaan

https://jabar.bps.go.id

PROVINSI : [32] JAWA BARAT
KAB/KOTA : [04] BANDUNG
KECAMATAN : [040] PANGALENGAN

Data Kemendagri			MFD 2021 Semester 2			
No	Kode	Nama Desa	No	Kode	Nama Desa	Status*
1	32.04.15.2012	WANASUKA	1	3204040001	WANASUKA	2
2	32.04.15.2008	BANJARSARI	2	3204040002	BANJARSARI	1
3	32.04.15.2002	MARGALUYU	3	3204040003	MARGALUYU	1
4	32.04.15.2009	SUKALUYU	4	3204040004	SUKALUYU	2
5	32.04.15.2003	WARNASARI	5	3204040005	WARNASARI	2
6	32.04.15.2011	PULOSARI	6	6320404006	PULOSARI	2
7	32.04.15.2013	MARGAMEKAR	7	3204040007	MARGAMEKAR	2
8	32.04.15.2004	SUKAMANAH	8	3204040008	SUKAMANAH	1
9	32.04.15.2006	MARGAMUKTI	9	3204040009	MARGAMUKTI	1
10	32.04.15.2001	PANGALEN-GAN	10	3204040010	PANGALEN-GAN	1
11	32.04.15.2007	MARGAMULYA	11	3204040011	MARGAMULYA	1
12	32.04.15.2010	TRIBAKTI MULYA	12	3204040012	TRIBAKTI MULYA	2
13	32.04.15.2005	LAMAJANG	13	3204040013	LAMAJANG	2

Catatan :
*) 1. Perkotaan
2. Perdesaan

https://jabar.bps.go.id

DAFTAR DESA/KELURAHAN

PROVINSI : [32] JAWA BARAT
KAB/KOTA : [04] BANDUNG
KECAMATAN : [050] KERTASARI

Data Kemendagri			MFD 2021 Semester 2			
No	Kode	Nama Desa	No	Kode	Nama Desa	Status*
1	32.04.31.2005	NEGLAWANGI	1	3204050001	NEGLAWANGI	2
2	32.04.31.2003	SANTOSA	2	3204050002	SANTOSA	1
3	32.04.31.2004	TARUMAJAYA	3	3204050003	TARUMAJAYA	1
4	32.04.31.2007	CIKEMBANG	4	3204050004	CIKEMBANG	1
5	32.04.31.2002	CIBEUREUM	5	3204050005	CIBEUREUM	1
6	32.04.31.2006	CIHAWUK	6	3204050006	CIHAWUK	2
7	32.04.31.2001	SUKAPURA	7	3204050007	SUKAPURA	1
8	32.04.31.2008	RESMI TINGAL	8	3204050008	RESMI TING-GAL	1

Catatan :
*) 1. Perkotaan
2. Perdesaan

https://jabar.bps.go.id

PROVINSI : [32] JAWA BARAT
KAB/KOTA : [04] BANDUNG
KECAMATAN : [060] PACET

Data Kemendagri			MFD 2021 Semester 2			
No	Kode	Nama Desa	No	Kode	Nama Desa	Status*
1	32.04.30.2002	CIKITU	1	3204060001	CIKITU	2
2	32.04.30.2011	GIRIMULYA	2	3204060002	GIRIMULYA	2
3	32.04.30.2005	SUKARAME	3	3204060003	SUKARAME	1
4	32.04.30.2007	CIKAWAO	4	3204060004	CIKAWAO	1
5	32.04.30.2006	NAGRAK	5	3204060005	NAGRAK	2
6	32.04.30.2010	MANDALAHAJI	6	3204060006	MANDALAHAJI	1
7	32.04.30.2004	MARUYUNG	7	3204060007	MARUYUNG	1
8	32.04.30.2009	PANGAUBAN	8	3204060008	PANGAUBAN	2
9	32.04.30.2003	CINANGGELA	9	3204060009	CINANGGELA	2
10	32.04.30.2008	MEKARJAYA	10	3204060010	MEKARJAYA	1
11	32.04.30.2013	MEKARSARI	11	3204060011	MEKARSARI	2
12	32.04.30.2001	CIPEUJEUH	12	3204060012	CIPEUJEUH	1
13	32.04.30.2012	TANJUNG-WANGI	13	3204060013	TANJUNG-WANGI	1

Catatan :
*) 1. Perkotaan
2. Perdesaan

https://jabar.bps.go.id

DAFTAR DESA/KELURAHAN

PROVINSI : [32] JAWA BARAT
KAB/KOTA : [04] BANDUNG
KECAMATAN : [070] IBUN

Data Kemendagri			MFD 2021 Semester 2			
No	Kode	Nama Desa	No	Kode	Nama Desa	Status*
1	32.04.36.2007	NEGLASARI	1	3204070001	NEGLASARI	2
2	32.04.36.2003	DUKUH	2	3204070002	DUKUH	1
3	32.04.36.2001	IBUN	3	3204070003	IBUN	1
4	32.04.36.2002	LAKSANA	4	3204070004	LAKSANA	1
5	32.04.36.2008	MEKARWANGI	5	3204070005	MEKARWANGI	2
6	32.04.36.2009	SUDI	6	3204070006	SUDI	1
7	32.04.36.2011	CIBEET	7	3204070007	CIBEET	1
8	32.04.36.2005	PANGGUH	8	3204070008	PANGGUH	1
9	32.04.36.2012	KARYALAKSA-NA	9	3204070009	KARYALAKSA-NA	1
10	32.04.36.2006	LAMPEGAN	10	3204070010	LAMPEGAN	1
11	32.04.36.2004	TALUN	11	3204070011	TALUN	1
12	32.04.36.2010	TANGGULUN	12	3204070012	TANGGULUN	1

https://jabar.bps.go.id

Catatan :
*) 1. Perkotaan
2. Perdesaan

PROVINSI : [32] JAWA BARAT
KAB/KOTA : [04] BANDUNG
KECAMATAN : [080] PASEH

Data Kemendagri			MFD 2021 Semester 2			
No	Kode	Nama Desa	No	Kode	Nama Desa	Status*
1	32.04.35.2003	LOA	1	3204080001	LOA	2
2	32.04.35.2007	DRAWATI	2	3204080002	DRAWATI	2
3	32.04.35.2005	CIPAKU	3	3204080003	CIPAKU	1
4	32.04.35.2006	SINDANGSARI	4	3204080004	SINDANGSARI	1
5	32.04.35.2009	SUKAMANTRI	5	3204080005	SUKAMANTRI	1
6	32.04.35.2008	SUKAMANAH	6	3204080006	SUKAMANAH	1
7	32.04.35.2011	MEKARPAWI TAN	7	3204080007	MEKARPAWI TAN	1
8	32.04.35.2004	CIJAGRA	8	3204080008	CIJAGRA	1
9	32.04.35.2012	TANGSIMEKAR	9	3204080009	TANGSIMEKAR	1
10	32.04.35.2002	CIPEDES	10	3204080010	CIPEDES	1
11	32.04.35.2010	KARANGTUNG-GAL	11	3204080011	KARANGTUNG-GAL	1
12	32.04.35.2001	CIGENTUR	12	3204080012	CIGENTUR	1

Catatan :
*) 1. Perkotaan
2. Perdesaan

https://jabar.bps.go.id

DAFTAR DESA/KELURAHAN

PROVINSI : [32] JAWA BARAT
KAB/KOTA : [04] BANDUNG
KECAMATAN : [090] CIKANCUNG

Data Kemendagri			MFD 2021 Semester 2			
No	Kode	Nama Desa	No	Kode	Nama Desa	Status*
1	32.04.27.2009	SRIRAHAYU	1	3204090001	SRIRAHAYU	2
2	32.04.27.2005	CILULUK	2	3204090002	CILULUK	1
3	32.04.27.2007	MEKARLAK-SANA	3	3204090003	MEKARLAK-SANA	2
4	32.04.27.2004	CIHANYIR	4	3204090004	CIHANYIR	1
5	32.04.27.2002	CIKANCUNG	5	3204090005	CIKANCUNG	1
6	32.04.27.2001	MANDALASARI	6	3204090006	MANDALASARI	1
7	32.04.27.2006	HEGARMANAH	7	3204090007	HEGARMANAH	1
8	32.04.27.2003	CIKASUNGKA	8	3204090008	CIKASUNGKA	1
9	32.04.27.2008	TANJUNGLAYA	9	3204090009	TANJUNGLAYA	1

Catatan :
*) 1. Perkotaan
2. Perdesaan

https://jabar.bps.go.id

PROVINSI : [32] JAWA BARAT
KAB/KOTA : [04] BANDUNG
KECAMATAN : [100] CICALENGKA

Data Kemendagri			MFD 2021 Semester 2			
No	Kode	Nama Desa	No	Kode	Nama Desa	Status*
1	32.04.25.2012	NAGROG	1	3204100001	NAGROG	1
2	32.04.25.2007	NARAWITA	2	3204100002	NARAWITA	1
3	32.04.25.2006	MARGAASIH	3	3204100003	MARGAASIH	1
4	32.04.25.2002	CICALENGKA WETAN	4	3204100004	CICALENGKA WETAN	1
5	32.04.25.2004	CIKUYA	5	3204100005	CIKUYA	1
6	32.04.25.2011	WALUYA	6	3204100006	WALUYA	1
7	32.04.25.2008	PANENJOAN	7	3204100007	PANENJOAN	1
8	32.04.25.2010	TENJOLAYA	8	3204100008	TENJOLAYA	1
9	32.04.25.2001	CICALENGKA KULON	9	3204100009	CICALENGKA KULON	1
10	32.04.25.2003	BABAKANPEU-TEUY	10	3204100010	BABAKANPEU-TEUY	1
11	32.04.25.2005	DAMPIT	11	3204100011	DAMPIT	2
12	32.04.25.2009	TANJUNG-WANGI	12	3204100012	TANJUNG-WANGI	2

Catatan :
*) 1. Perkotaan
2. Perdesaan

https://jabar.bps.go.id

DAFTAR DESA/KELURAHAN

PROVINSI : [32] JAWA BARAT
KAB/KOTA : [04] BANDUNG
KECAMATAN : [101] NAGREG

Data Kemendagri			MFD 2021 Semester 2			
No	Kode	Nama Desa	No	Kode	Nama Desa	Status*
1	32.04.26.2006	MANDALA-WANGI	1	3204101001	MANDALA-WANGI	2
2	32.04.26.2002	BOJONG	2	3204101002	BOJONG	2
3	32.04.26.2004	CIHERANG	3	3204101003	CIHERANG	2
4	32.04.26.2003	CIARO	4	3204101004	CIARO	2
5	32.04.26.2001	NAGREG	5	3204101005	NAGREG	2
6	32.04.26.2005	CITAMAN	6	3204101006	CITAMAN	1
7	32.04.26.2007	NAGREG KEN-DAN	7	3204101007	NAGREG KEN-DAN	2
8	32.04.26.2008	GANJAR SABAR	8	3204101008	GANJAR SABAR	1

Catatan :
*) 1. Perkotaan
2. Perdesaan

https://jabar.bps.go.id

PROVINSI : [32] JAWA BARAT
KAB/KOTA : [04] BANDUNG
KECAMATAN : [110] RANCAEKEK

Data Kemendagri			MFD 2021 Semester 2			
No	Kode	Nama Desa	No	Kode	Nama Desa	Status*
1	32.04.28.2009	SUKAMANAH	1	3204110001	SUKAMANAH	1
2	32.04.28.2011	TEGALSUMED-ANG	2	3204110002	TEGALSUMED-ANG	2
3	32.04.28.2002	RANCAEKEK KULON	3	3204110003	RANCAEKEK KULON	1
4	32.04.28.2001	RANCAEKEK WETAN	4	3204110004	RANCAEKEK WETAN	1
5	32.04.28.2004	BOJONGLOA	5	3204110005	BOJONGLOA	1
6	32.04.28.2005	JELEGONG	6	3204110006	JELEGONG	1
7	32.04.28.2006	LINGGAR	7	3204110007	LINGGAR	1
8	32.04.28.2010	SUKAMULYA	8	3204110008	SUKAMULYA	1
9	32.04.28.2008	HAURPUGUR	9	3204110009	HAURPUGUR	2
10	32.04.28.2012	SANGIANG	10	3204110010	SANGIANG	1
11	32.04.28.2003	BOJONG-SALAM	11	3204110011	BOJONG-SALAM	2
12	32.04.28.2007	CANGKUANG	12	3204110012	CANGKUANG	1
13	32.04.28.2013	NANJUNG MEKAR	13	3204110013	NANJUNGME-KAR	1
14	32.04.28.1014	RANCAEKEK KENCANA	14	3204110014	RANCAEKEK KENCANA	1

https://jabar.bps.go.id

Catatan :
*) 1. Perkotaan
2. Perdesaan

DAFTAR DESA/KELURAHAN

PROVINSI : [32] JAWA BARAT
KAB/KOTA : [04] BANDUNG
KECAMATAN : [120] MAJALAYA

Data Kemendagri			MFD 2021 Semester 2			
No	Kode	Nama Desa	No	Kode	Nama Desa	Status*
1	32.04.33.2010	NEGLASARI	1	3204120001	NEGLASARI	1
2	32.04.33.2002	WANGISAGA-RA	2	3204120002	WANGISAGA-RA	1
3	32.04.33.2004	PADAMULYA	3	3204120003	PADAMULYA	1
4	32.04.33.2011	SUKAMUKTI	4	3204120004	SUKAMUKTI	1
5	32.04.33.2009	PADAULUN	5	3204120005	PADAULUN	1
6	32.04.33.2003	BIRU	6	3204120006	BIRU	1
7	32.04.33.2008	SUKAMAJU	7	3204120007	SUKAMAJU	1
8	32.04.33.2006	MAJASETRA	8	3204120008	MAJASETRA	1
9	32.04.33.2001	MAJALAYA	9	3204120009	MAJALAYA	1
10	32.04.33.2007	MAJAKERTA	10	3204120010	MAJAKERTA	1
11	32.04.33.2005	BOJONG	11	3204120011	BOJONG	1

Catatan :
*) 1. Perkotaan
2. Perdesaan

https://jabar.bps.go.id

PROVINSI : [32] JAWA BARAT
KAB/KOTA : [04] BANDUNG
KECAMATAN : [121] SOLOKAN JERUK

Data Kemendagri			MFD 2021 Semester 2			
No	Kode	Nama Desa	No	Kode	Nama Desa	Status*
1	32.04.34.2004	PANYADAP	1	3204121001	PANYADAP	1
2	32.04.34.2006	PADAMUKTI	2	3204121002	PADAMUKTI	1
3	32.04.34.2003	CIBODAS	3	3204121003	CIBODAS	1
4	32.04.34.2007	LANGENSARI	4	3204121004	LANGENSARI	1
5	32.04.34.2002	SOLOKANJE-RUK	5	3204121005	SOLOKANJE-RUK	1
6	32.04.34.2001	RANCAKA-SUMBA	6	3204121006	RANCAKA-SUMBA	1
7	32.04.34.2005	BOJONGEMAS	7	3204121007	BOJONGEMAS	1

Catatan :
*) 1. Perkotaan
2. Perdesaan

https://jabar.bps.go.id

DAFTAR DESA/KELURAHAN

PROVINSI : [32] JAWA BARAT
KAB/KOTA : [04] BANDUNG
KECAMATAN : [130] CIPARAY

Data Kemendagri			MFD 2021 Semester 2			
No	Kode	Nama Desa	No	Kode	Nama Desa	Status*
1	32.04.29.2012	BABAKAN	1	3204130001	BABAKAN	1
2	32.04.29.2004	CIKONENG	2	3204130002	CIKONENG	1
3	32.04.29.2009	SAGALACIPTA	3	3204130003	SAGALACIPTA	2
4	32.04.29.2006	PAKUTAN-DANG	4	3204130004	PAKUTAN-DANG	1
5	32.04.29.2008	MANGGUNG-HARJA	5	3204130005	MANGGUNG-HARJA	1
6	32.04.29.2003	MEKARSARI	6	3204130006	MEKARSARI	1
7	32.04.29.2001	CIPARAY	7	3204130007	CIPARAY	1
8	32.04.29.2007	SUMBERSARI	8	3204130008	SUMBERSARI	1
9	32.04.29.2010	SARIMAHI	9	3204130009	SARIMAHI	1
10	32.04.29.2011	SERANGME-KAR	10	3204130010	SERANGME-KAR	1
11	32.04.29.2002	GUNUNGLEU-TIK	11	3204130011	GUNUNGLEU-TIK	1
12	32.04.29.2005	CIHEULANG	12	3204130012	CIHEULANG	1
13	32.04.29.2014	MEKARLAK-SANA	13	3204130013	MEKARLAK-SANA	1
14	32.04.29.2013	BUMIWANGI	14	3204130014	BUMIWANGI	1

Catatan :
*) 1. Perkotaan
2. Perdesaan

https://jabar.bps.go.id

PROVINSI : [32] JAWA BARAT
KAB/KOTA : [04] BANDUNG
KECAMATAN : [140] BALEENDAH

Data Kemendagri			MFD 2021 Semester 2			
No	Kode	Nama Desa	No	Kode	Nama Desa	Status*
1	32.04.32.1004	JELEKONG	1	3204140001	JELEKONG	1
2	32.04.32.1003	MANGGAHANG	2	3204140002	MANGGAHANG	1
3	32.04.32.1001	BALEENDAH	3	3204140003	BALEENDAH	1
4	32.04.32.1002	ANDIR	4	3204140004	ANDIR	1
5	32.04.32.2007	MALAKASARI	5	3204140005	MALAKASARI	1
6	32.04.32.2005	BOJONG MALAKA	6	3204140006	BOJONG MALAKA	1
7	32.04.32.2006	RANCAMANYAR	7	3204140007	RANCAMANYAR	1
8	32.04.32.1008	WARGAMEKAR	8	3204140008	WARGAMEKAR	1

Catatan :
*) 1. Perkotaan
2. Perdesaan

https://jabar.bps.go.id

DAFTAR DESA/KELURAHAN

PROVINSI : [32] JAWA BARAT
KAB/KOTA : [04] BANDUNG
KECAMATAN : [150] ARJASARI

Data Kemendagri			MFD 2021 Semester 2			
No	Kode	Nama Desa	No	Kode	Nama Desa	Status*
1	32.04.16.2003	BATUKARUT	1	3204150001	BATUKARUT	1
2	32.04.16.2006	MANGUNJAYA	2	3204150002	MANGUNJAYA	2
3	32.04.16.2007	MEKARJAYA	3	3204150003	MEKARJAYA	2
4	32.04.16.2005	BAROS	4	3204150004	BAROS	2
5	32.04.16.2002	LEBAKWANGI	5	3204150005	LEBAKWANGI	1
6	32.04.16.2011	WARGALUYU	6	3204150006	WARGALUYU	2
7	32.04.16.2001	ARJASARI	7	3204150007	ARJASARI	2
8	32.04.16.2008	PINGGIRSARI	8	3204150008	PINGGIRSARI	2
9	32.04.16.2009	PATROLSARI	9	3204150009	PATROLSARI	2
10	32.04.16.2010	RANCAKOLE	10	3204150010	RANCAKOLE	1
11	32.04.16.2004	ANCOLMEKAR	11	3204150011	ANCOLMEKAR	2

Catatan :
*) 1. Perkotaan
2. Perdesaan

https://jabar.bps.go.id

PROVINSI : [32] JAWA BARAT
KAB/KOTA : [04] BANDUNG
KECAMATAN : [160] BANJARAN

Data Kemendagri			MFD 2021 Semester 2			
No	Kode	Nama Desa	No	Kode	Nama Desa	Status*
1	32.04.13.2012	MEKARJAYA	1	3204160001	MEKARJAYA	2
2	32.04.13.2002	BANJARAN WETAN	2	3204160002	BANJARAN WETAN	1
3	32.04.13.2005	CIAPUS	3	3204160003	CIAPUS	1
4	32.04.13.2006	SINDANG-PANON	4	3204160004	SINDANG-PANON	1
5	32.04.13.2016	NEGLASARI	5	3204160005	NEGLASARI	1
6	32.04.13.2013	MARGAHURIP	6	3204160006	MARGAHURIP	1
7	32.04.13.2007	KIANGROKE	7	3204160007	KIANGROKE	1
8	32.04.13.2001	KAMASAN	8	3204160008	KAMASAN	1
9	32.04.13.2003	BANJARAN	9	3204160009	BANJARAN	1
10	32.04.13.2008	TARAJUSARI	10	3204160010	TARAJUSARI	1
11	32.04.13.2018	PASIRMULYA	11	3204160011	PASIRMULYA	1

Catatan :
*) 1. Perkotaan
2. Perdesaan

https://jabar.bps.go.id

DAFTAR DESA/KELURAHAN

PROVINSI : [32] JAWA BARAT
KAB/KOTA : [04] BANDUNG
KECAMATAN : [161] CANGKUANG

Data Kemendagri			MFD 2021 Semester 2			
No	Kode	Nama Desa	No	Kode	Nama Desa	Status*
1	32.04.44.2006	JATISARI	1	3204161001	JATISARI	1
2	32.04.44.2003	NAGRAK	2	3204161002	NAGRAK	1
3	32.04.44.2004	BANDASARI	3	3204161003	BANDASARI	2
4	32.04.44.2005	PANANJUNG	4	3204161004	PANANJUNG	1
5	32.04.44.2002	CILUNCAT	5	3204161005	CILUNCAT	1
6	32.04.44.2001	CANGKUANG	6	3204161006	CANGKUANG	1
7	32.04.44.2007	TANJUNGSARI	7	3204161007	TANJUNGSARI	1

Catatan :
*) 1. Perkotaan
2. Perdesaan

https://jabar.bps.go.id

PROVINSI : [32] JAWA BARAT
KAB/KOTA : [04] BANDUNG
KECAMATAN : [170] PAMEUNGPEUK

Data Kemendagri			MFD 2021 Semester 2			
No	Kode	Nama Desa	No	Kode	Nama Desa	Status*
1	32.04.15.2002	BOJONG-MANGGU	1	3204170001	BOJONG-MANGGU	1
2	32.04.15.2006	LANGONSARI	2	3204170002	LANGONSARI	1
3	32.04.15.2001	SUKASARI	3	3204170003	SUKASARI	1
4	32.04.15.2005	RANCAMULYA	4	3204170004	RANCAMULYA	1
5	32.04.15.2003	RANCA-TUNGKU	5	3204170005	RANCA-TUNGKU	1
6	32.04.15.2004	BOJONGKUNCI	6	3204170006	BOJONGKUNCI	1

Catatan :
*) 1. Perkotaan
2. Perdesaan

https://jabar.bps.go.id

DAFTAR DESA/KELURAHAN

PROVINSI : [32] JAWA BARAT
KAB/KOTA : [04] BANDUNG
KECAMATAN : [180] KATAPANG

Data Kemendagri			MFD 2021 Semester 2			
No	Kode	Nama Desa	No	Kode	Nama Desa	Status*
1	32.04.11.2004	GANDASARI	1	3204180004	GANDASARI	1
2	32.04.11.2002	KATAPANG	2	3204180005	KATAPANG	1
3	32.04.11.2007	CILAMPENI	3	3204180006	CILAMPENI	1
4	32.04.11.2008	PANGAUBAN	4	3204180007	PANGAUBAN	1
5	32.04.11.2009	BANYUSARI	5	3204180008	BANYUSARI	1
6	32.04.11.2001	SANGKANHU-RIP	6	3204180009	SANGKANHU-RIP	1
7	32.04.11.2006	SUKAMUKTI	7	3204180010	SUKAMUKTI	1

Catatan :
*) 1. Perkotaan
2. Perdesaan

https://jabar.bps.go.id

PROVINSI : [32] JAWA BARAT
KAB/KOTA : [04] BANDUNG
KECAMATAN : [190] SOREANG

Data Kemendagri			MFD 2021 Semester 2			
No	Kode	Nama Desa	No	Kode	Nama Desa	Status*
1	32.04.37.2002	SADU	1	3204190002	SADU	1
2	32.04.37.2010	SUKAJADI	2	3204190003	SUKAJADI	2
3	32.04.37.2018	SUKANAGARA	3	3204190004	SUKANAGARA	2
4	32.04.37.2004	PANYIRAPAN	4	3204190005	PANYIRAPAN	1
5	32.04.37.2017	KARAMAT MULYA	5	3204190006	KARAMAT MULYA	1
6	32.04.37.2001	SOREANG	6	3204190007	SOREANG	1
7	32.04.37.2011	PAMEKARAN	7	3204190008	PAMEKARAN	1
8	32.04.37.2020	PARUNGSERAB	8	3204190019	PARUNGSERAB	1
9	32.04.37.2021	SEKARWANGI	9	3204190020	SEKARWANGI	1
10	32.04.37.2019	CINGCIN	10	3204190021	CINGCIN	1

Catatan :
*) 1. Perkotaan
2. Perdesaan

https://jabar.bps.go.id

DAFTAR DESA/KELURAHAN

PROVINSI : [32] JAWA BARAT
KAB/KOTA : [04] BANDUNG
KECAMATAN : [191] KUTAWARINGIN

Data Kemendagri			MFD 2021 Semester 2			
No	Kode	Nama Desa	No	Kode	Nama Desa	Status*
1	32.04.46.2011	CILAME	1	3204191001	CILAME	1
2	32.04.46.2009	BUNINAGARA	2	3204191002	BUNINAGARA	2
3	32.04.46.2008	PADASUKA	3	3204191003	PADASUKA	1
4	32.04.46.2007	SUKAMULYA	4	3204191004	SUKAMULYA	2
5	32.04.46.2006	KUTAWARINGIN	5	3204191005	KUTAWARINGIN	2
6	32.04.46.2004	KOPO	6	3204191006	KOPO	1
7	32.04.46.2005	CIBODAS	7	3204191007	CIBODAS	2
8	32.04.46.2002	JATISARI	8	3204191008	JATISARI	2
9	32.04.46.2001	JELEGONG	9	3204191009	JELEGONG	2
10	32.04.46.2010	GAJAHMEKAR	10	3204191010	GAJAHMEKAR	1
11	32.04.46.2003	PAMEUNTASAN	11	3204191011	PAMEUNTASAN	2

https://jabar.bps.go.id

Catatan :
*) 1. Perkotaan
2. Perdesaan

PROVINSI : [32] JAWA BARAT
KAB/KOTA : [04] BANDUNG
KECAMATAN : [250] MARGAASIH

Data Kemendagri			MFD 2021 Semester 2			
No	Kode	Nama Desa	No	Kode	Nama Desa	Status*
1	32.04.10.2003	NANJUNG	1	3204250001	NANJUNG	1
2	32.04.10.2004	MEKARRA-HAYU	2	3204250002	MEKAR RA-HAYU	1
3	32.04.10.2005	RAHAYU	3	3204250003	RAHAYU	1
4	32.04.10.2006	CIGONDEWAH HILIR	4	3204250004	CIGONDEWAH HILIR	1
5	32.04.10.2001	MARGAASIH	5	3204250005	MARGAASIH	1
6	32.04.10.2002	LAGADAR	6	3204250006	LAGADAR	1

Catatan :
*) 1. Perkotaan
2. Perdesaan

https://jabar.bps.go.id

DAFTAR DESA/KELURAHAN

PROVINSI : [32] JAWA BARAT
KAB/KOTA : [04] BANDUNG
KECAMATAN : [260] MARGAHAYU

Data Kemendagri			MFD 2021 Semester 2			
No	Kode	Nama Desa	No	Kode	Nama Desa	Status*
1	32.04.09.1004	SULAIMAN	1	3204260001	SULAEMAN	1
2	32.04.09.2003	SUKAMENAK	2	3204260002	SUKAMENAK	1
3	32.04.09.2005	SAYATI	3	3204260003	SAYATI	1
4	32.04.09.2002	MARGAHAYU SELATAN	4	3204260004	MARGAHAYU SELATAN	1
5	32.04.09.2001	MARGAHAYU TENGAH	5	3204260005	MARGAHAYU TENGAH	1

Catatan :
*) 1. Perkotaan
2. Perdesaan

https://jabar.bps.go.id

PROVINSI : [32] JAWA BARAT
KAB/KOTA : [04] BANDUNG
KECAMATAN : [270] DAYEUHKOLOT

Data Kemendagri			MFD 2021 Semester 2			
No	Kode	Nama Desa	No	Kode	Nama Desa	Status*
1	32.04.12.2004	CANGKUANG KULON	1	3204270001	CANGKUANG KULON	1
2	32.04.12.2003	CANGKUANG WETAN	2	3204270002	CANGKUANG WETAN	1
3	32.04.12.1001	PASAWAHAN	3	3204270003	PASAWAHAN	1
4	32.04.12.2002	DAYEUHKOLOT	4	3204270004	DAYEUHKOLOT	1
5	32.04.12.2006	CITEUREUP	5	3204270005	CITEUREUP	1
6	32.04.12.2005	SUKAPURA	6	3204270006	SUKAPURA	1

Catatan :
*) 1. Perkotaan
2. Perdesaan

https://jabar.bps.go.id

DAFTAR DESA/KELURAHAN

PROVINSI : [32] JAWA BARAT
KAB/KOTA : [04] BANDUNG
KECAMATAN : [280] BOJONGSOANG

Data Kemendagri			MFD 2021 Semester 2			
No	Kode	Nama Desa	No	Kode	Nama Desa	Status*
1	32.04.08.2005	BOJONGSARI	1	3204280001	BOJONGSARI	1
2	32.04.08.2002	BOJONG-SOANG	2	3204280002	BOJONG-SOANG	1
3	32.04.08.2001	LENGKONG	3	3204280003	LENGKONG	1
4	32.04.08.2004	CIPAGALO	4	3204280004	CIPAGALO	1
5	32.04.08.2003	BUAH BATU	5	3204280005	BUAH BATU	1
6	32.04.08.2006	TEGALLUAR	6	3204280006	TEGALLUAR	2

Catatan :
*) 1. Perkotaan
2. Perdesaan

https://jabar.bps.go.id

PROVINSI : [32] JAWA BARAT
KAB/KOTA : [04] BANDUNG
KECAMATAN : [290] CILEUNYI

Data Kemendagri			MFD 2021 Semester 2			
No	Kode	Nama Desa	No	Kode	Nama Desa	Status*
1	32.04.05.2005	CIBIRU HILIR	1	3204290001	CIBIRU HILIR	1
2	32.04.05.2004	CINUNUK	2	3204290002	CINUNUK	1
3	32.04.05.2003	CIMEKAR	3	3204290003	CIMEKAR	1
4	32.04.05.2001	CILEUNYI KULON	4	3204290004	CILEUNYI KULON	1
5	32.04.05.2002	CILEUNYI WETAN	5	3204290005	CILEUNYI WETAN	1
6	32.04.05.2006	CIBIRU WETAN	6	3204290006	CIBIRU WETAN	1

Catatan :
*) 1. Perkotaan
2. Perdesaan

https://jabar.bps.go.id

DAFTAR DESA/KELURAHAN

PROVINSI : [32] JAWA BARAT
KAB/KOTA : [04] BANDUNG
KECAMATAN : [300] CILENGKRANG

Data Kemendagri			MFD 2021 Semester 2			
No	Kode	Nama Desa	No	Kode	Nama Desa	Status*
1	32.04.07.2006	GIRIMEKAR	1	3204300001	GIRIMEKAR	1
2	32.04.07.2001	JATIENDAH	2	3204300002	JATIENDAH	1
3	32.04.07.2004	MELATIWANGI	3	3204300003	MELATIWANGI	1
4	32.04.07.2003	CIPANJALU	4	3204300004	CIPANJALU	2
5	32.04.07.2005	CIPOREAT	5	3204300005	CIPOREAT	2
6	32.04.07.2002	CILENGKRANG	6	3204300006	CILENGKRANG	1

Catatan :
*) 1. Perkotaan
2. Perdesaan

https://jabar.bps.go.id

PROVINSI : [32] JAWA BARAT
KAB/KOTA : [04] BANDUNG
KECAMATAN : [310] CIMENYAN

Data Kemendagri			MFD 2021 Semester 2			
No	Kode	Nama Desa	No	Kode	Nama Desa	Status*
1	32.04.06.1002	CIBEUNYING	1	3204310001	CIBEUNYING	1
2	32.04.06.1001	PADASUKA	2	3204310002	PADASUKA	1
3	32.04.06.2004	MANDALAME-KAR	3	3204310003	MANDALAME-KAR	1
4	32.04.06.2005	CIKADUT	4	3204310004	CIKADUT	1
5	32.04.06.2007	SINDANGLAYA	5	3204310005	SINDANGLAYA	1
6	32.04.06.2009	MEKARMANIK	6	3204310006	MEKARMANIK	2
7	32.04.06.2003	CIMENYAN	7	3204310007	CIMENYAN	2
8	32.04.06.2008	MEKARSALUYU	8	3204310008	MEKARSALUYU	2
9	32.04.06.2006	CIBURIAL	9	3204310009	CIBURIAL	1

Catatan :
*) 1. Perkotaan
2. Perdesaan

https://jabar.bps.go.id

https://jabar.bps.go.id

KABUPATEN GARUT

https://jabar.bps.go.id

https://jabar.bps.go.id

PROVINSI : [32] JAWA BARAT
KAB/KOTA : [05] GARUT

Data Kemendagri			MFD 2021 Semester 2		
No	Kode	Nama Kecamatan	No	Kode	Nama Kecamatan
1	32.05.35	CISEWU	1	3205010	CISEWU
2	32.05.36	CARINGIN	2	3205011	CARINGIN
3	32.05.37	TALEGONG	3	3205020	TALEGONG
4	32.05.31	BUNGBULANG	4	3205030	BUNGBULANG
5	32.05.32	MEKARMUKTI	5	3205031	MEKARMUKTI
6	32.05.34	PAMULIHAN	6	3205040	PAMULIHAN
7	32.05.33	PAKENJENG	7	3205050	PAKENJENG
8	32.05.30	CIKELET	8	3205060	CIKELET
9	32.05.27	PAMEUNGPEUK	9	3205070	PAMEUNGPEUK
10	32.05.29	CIBALONG	10	3205080	CIBALONG
11	32.05.28	CISOMPET	11	3205090	CISOMPET
12	32.05.26	PEUNDEUY	12	3205100	PEUNDEUY
13	32.05.24	SINGAJAYA	13	3205110	SINGAJAYA
14	32.05.25	CIHURIP	14	3205111	CIHURIP
15	32.05.22	CIKAJANG	15	3205120	CIKAJANG
16	32.05.23	BANJARWANGI	16	3205130	BANJARWANGI
17	32.05.19	CILAWU	17	3205140	CILAWU
18	32.05.17	BAYONGBONG	18	3205150	BAYONGBONG
19	32.05.18	CIGEDUG	19	3205151	CIGEDUG
20	32.05.20	CISURUPAN	20	3205160	CISURUPAN
21	32.05.21	SUKARESMI	21	3205161	SUKARESMI
22	32.05.07	SAMARANG	22	3205170	SAMARANG
23	32.05.08	PASIRWANGI	23	3205171	PASIRWANGI
24	32.05.05	TAROGONG KIDUL	24	3205181	TAROGONG KIDUL

https://jabar.bps.go.id

DAFTAR KECAMATAN

PROVINSI : [32] JAWA BARAT
KAB/KOTA : [05] GARUT

Data Kemendagri			MFD 2021 Semester 2		
No	Kode	Nama Kecamatan	No	Kode	Nama Kecamatan
25	32.05.04	TAROGONG KALER	25	3205182	TAROGONG KALER
26	32.05.01	GARUT KOTA	26	3205190	GARUT KOTA
27	32.05.02	KARANGPAWITAN	27	3205200	KARANGPAWITAN
28	32.05.03	WANARAJA	28	3205210	WANARAJA
29	32.05.42	SUCINARAJA	29	3205211	SUCINARAJA
30	32.05.41	PANGATIKAN	30	3205212	PANGATIKAN
31	32.05.15	SUKAWENING	31	3205220	SUKAWENING
32	32.05.16	KARANGTENGAH	32	3205221	KARANGTENGAH
33	32.05.06	BANYURESMI	33	3205230	BANYURESMI
34	32.05.09	LELES	34	3205240	LELES
35	32.05.11	LEUWIGOONG	35	3205250	LEUWIGOONG
36	32.05.12	CIBATU	36	3205260	CIBATU
37	32.05.13	KERSAMANAH	37	3205261	KERSAMANAH
38	32.05.40	CIBIUK	38	3205270	CIBIUK
39	32.05.10	KADUNGORA	39	3205280	KADUNGORA
40	32.05.38	BL. LIMBANGAN	40	3205290	BLUBUR LIMBANGAN
41	32.05.39	SELAAWI	41	3205300	SELAAWI
42	32.05.14	MALANGBONG	42	3205310	MALANGBONG

https://jabar.bps.go.id

JUMLAH DESA/KELURAHAN PER KECAMATAN

PROVINSI : [32] JAWA BARAT
KAB/KOTA : [05] GARUT

Data Kemendagri				MFD 2021 Semester 2			
No	Kode	Nama Kecamatan	Jml Desa	No	Kode	Nama Kecamatan	Jml Desa
1	32.05.35	CISEWU	9	1	3205010	CISEWU	9
2	32.05.36	CARINGIN	6	2	3205011	CARINGIN	6
3	32.05.37	TALEGONG	7	3	3205020	TALEGONG	7
4	32.05.31	BUNGBULANG	13	4	3205030	BUNGBULANG	13
5	32.05.32	MEKARMUKTI	5	5	3205031	MEKARMUKTI	5
6	32.05.34	PAMULIHAN	5	6	3205040	PAMULIHAN	5
7	32.05.33	PAKENJENG	13	7	3205050	PAKENJENG	13
8	32.05.30	CIKELET	11	8	3205060	CIKELET	11
9	32.05.27	PAMEUNGPEUK	8	9	3205070	PAMEUNGPEUK	8
10	32.05.29	CIBALONG	11	10	3205080	CIBALONG	11
11	32.05.28	CISOMPET	11	11	3205090	CISOMPET	11
12	32.05.26	PEUNDEUY	6	12	3205100	PEUNDEUY	6
13	32.05.24	SINGAJAYA	9	13	3205110	SINGAJAYA	9
14	32.05.25	CIHURIP	4	14	3205111	CIHURIP	4
15	32.05.22	CIKAJANG	12	15	3205120	CIKAJANG	12
16	32.05.23	BANJARWANGI	11	16	3205130	BANJARWANGI	11
17	32.05.19	CILAWU	18	17	3205140	CILAWU	18
18	32.05.17	BAYONGBONG	5	18	3205150	BAYONGBONG	5
19	32.05.18	CIGEDUG	17	19	3205151	CIGEDUG	17
20	32.05.20	CISURUPAN	7	20	3205160	CISURUPAN	7
21	32.05.21	SUKARESMI	13	21	3205161	SUKARESMI	13

https://jabar.bps.go.id

JUMLAH DESA/KELURAHAN PER KECAMATAN

PROVINSI : [32] JAWA BARAT
KAB/KOTA : [05] GARUT

Data Kemendagri				MFD 2021 Semester 2			
No	Kode	Nama Kecamatan	Jml Desa	No	Kode	Nama Kecamatan	Jml Desa
22	32.05.07	SAMARANG	12	22	3205170	SAMARANG	12
23	32.05.08	PASIRWANGI	12	23	3205171	PASIRWANGI	12
24	32.05.05	TAROGONG KIDUL	13	24	3205181	TAROGONG KIDUL	13
25	32.05.04	TAROGONG KALER	11	25	3205182	TAROGONG KALER	11
26	32.05.01	GARUT KOTA	20	26	3205190	GARUT KOTA	20
27	32.05.02	KARANGPAWITAN	9	27	3205200	KARANGPAWITAN	9
28	32.05.03	WANARAJA	9	28	3205210	WANARAJA	9
29	32.05.42	SUCINARAJA	7	29	3205211	SUCINARAJA	7
30	32.05.41	PANGATIKAN	8	30	3205212	PANGATIKAN	8
31	32.05.15	SUKAWENING	11	31	3205220	SUKAWENING	11
32	32.05.16	KARANGTENGAH	4	32	3205221	KARANGTENGAH	4
33	32.05.06	BANYURESMI	15	33	3205230	BANYURESMI	15
34	32.05.09	LELES	12	34	3205240	LELES	12
35	32.05.11	LEUWIGOONG	8	35	3205250	LEUWIGOONG	8
36	32.05.12	CIBATU	11	36	3205260	CIBATU	11
37	32.05.13	KERSAMANAH	6	37	3205261	KERSAMANAH	6
38	32.05.40	CIBIUK	5	38	3205270	CIBIUK	5
39	32.05.10	KADUNGORA	14	39	3205280	KADUNGORA	14
40	32.05.38	BL. LIMBANGAN	14	40	3205290	BLUBUR LIMBAN-GAN	14
41	32.05.39	SELAAWI	7	41	3205300	SELAAWI	7
42	32.05.14	MALANGBONG	24	42	3205310	MALANGBONG	24

https://jabar.bps.go.id

PROVINSI : [32] JAWA BARAT
KAB/KOTA : [05] GARUT
KECAMATAN : [010] CISEWU

Data Kemendagri			MFD 2021 Semester 2			
No	Kode	Nama Desa	No	Kode	Nama Desa	Status*
1	32.05.35.2005	SUKAJAYA	1	3205010006	SUKAJAYA	2
2	32.05.35.2004	CIKARANG	2	3205010007	CIKARANG	2
3	32.05.35.2003	PAMALAYAN	3	3205010008	PAMALAYAN	2
4	32.05.35.2001	CISEWU	4	3205010009	CISEWU	2
5	32.05.35.2002	GIRIMUKTI	5	3205010010	GIRIMUKTI	2
6	32.05.35.2006	NYALINDUNG	6	3205010011	NYALINDUNG	2
7	32.05.35.2007	KARANGSEWU	7	3205010012	KARANGSEWU	2
8	32.05.35.2008	MEKARSEWU	8	3205010013	MEKARSEWU	2
9	32.05.35.2009	PANGGALIH	9	3205010014	PANGGALIH	2

Catatan :
*) 1. Perkotaan
2. Perdesaan

https://jabar.bps.go.id

DAFTAR DESA/KELURAHAN

PROVINSI : [32] JAWA BARAT
KAB/KOTA : [05] GARUT
KECAMATAN : [011] CARINGIN

Data Kemendagri			MFD 2021 Semester 2			
No	Kode	Nama Desa	No	Kode	Nama Desa	Status*
1	32.05.36.2003	CIMAHI	1	3205011001	CIMAHI	2
2	32.05.36.2002	INDRALAYANG	2	3205011002	INDRALAYANG	2
3	32.05.36.2005	PURBAYANI	3	3205011003	PURBAYANI	2
4	32.05.36.2001	CARINGIN	4	3205011004	CARINGIN	2
5	32.05.36.2004	SUKARAME	5	3205011005	SUKARAME	2
6	32.05.36.2006	SAMUDERA-JAYA	6	3205011006	SAMUDRAJAYA	2

Catatan :
*) 1. Perkotaan
2. Perdesaan

https://jabar.bps.go.id

PROVINSI : [32] JAWA BARAT
KAB/KOTA : [05] GARUT
KECAMATAN : [020] TALEGONG

Data Kemendagri			MFD 2021 Semester 2			
No	Kode	Nama Desa	No	Kode	Nama Desa	Status*
1	32.05.37.2006	SELAAWI	1	3205020001	SELAAWI	2
2	32.05.37.2003	MEKARMUKTI	2	3205020002	MEKARMUKTI	2
3	32.05.37.2004	MEKARMULYA	3	3205020003	MEKARMULYA	2
4	32.05.37.2002	SUKAMULYA	4	3205020004	SUKAMULYA	2
5	32.05.37.2001	SUKAMAJU	5	3205020005	SUKAMAJU	2
6	32.05.37.2005	SUKALAKSANA	6	3205020006	SUKALAKSANA	2
7	32.05.37.2007	MEKARWANGI	7	3205020007	MEKARWANGI	2

Catatan :
*) 1. Perkotaan
2. Perdesaan

https://jabar.bps.go.id

DAFTAR DESA/KELURAHAN

PROVINSI : [32] JAWA BARAT
KAB/KOTA : [05] GARUT
KECAMATAN : [030] BUNGBULANG

Data Kemendagri			MFD 2021 Semester 2			
No	Kode	Nama Desa	No	Kode	Nama Desa	Status*
1	32.05.31.2008	SINARJAYA	1	3205030001	SINARJAYA	2
2	32.05.31.2004	TEGALLEGA	2	3205030005	TEGALLEGA	2
3	32.05.31.2011	WANGUNJAYA	3	3205030006	WANGUNJAYA	2
4	32.05.31.2009	MEKARJAYA	4	3205030007	MEKARJAYA	2
5	32.05.31.2002	HANJUANG	5	3205030008	HANJUANG	1
6	32.05.31.2006	MARGALAK-SANA	6	3205030009	MARGALAK-SANA	2
7	32.05.31.2003	GUNAMEKAR	7	3205030010	GUNAMEKAR	2
8	32.05.31.2001	BUNGBULANG	8	3205030011	BUNGBULANG	1
9	32.05.31.2010	CIHIKEU	9	3205030012	CIHIKEU	2
10	32.05.31.2007	BOJONG	10	3205030013	BOJONG	2
11	32.05.31.2005	MEKARBAKTI	11	3205030014	MEKARBAKTI	2
12	32.05.31.2012	GUNUNG JAMPANG	12	3205030015	GUNUNG JAMPANG	2
13	32.05.31.2013	HEGARMANAH	13	3205030016	HEGARMANAH	1

Catatan :
*) 1. Perkotaan
2. Perdesaan

https://jabar.bps.go.id

PROVINSI : [32] JAWA BARAT
KAB/KOTA : [05] GARUT
KECAMATAN : [031] MEKARMUKTI

Data Kemendagri			MFD 2021 Semester 2			
No	Kode	Nama Desa	No	Kode	Nama Desa	Status*
1	32.05.32.2002	KARANG WANGI	1	3205031001	KARANG WANGI	2
2	32.05.32.2004	CIJAYANA	2	3205031002	CIJAYANA	2
3	32.05.32.2001	MEKARMUKTI	3	3205031003	MEKARMUKTI	2
4	32.05.32.2003	JAGABAYA	4	3205031004	JAGABAYA	2
5	32.05.32.2005	MEKARSARI	5	3205031005	MEKARSARI	2

Catatan :
*) 1. Perkotaan
2. Perdesaan

https://jabar.bps.go.id

DAFTAR DESA/KELURAHAN

PROVINSI : [32] JAWA BARAT
KAB/KOTA : [05] GARUT
KECAMATAN : [040] PAMULIHAN

Data Kemendagri			MFD 2021 Semester 2			
No	Kode	Nama Desa	No	Kode	Nama Desa	Status*
1	32.05.34.2005	LINGGARJATI	1	3205040001	LINGGARJATI	2
2	32.05.34.2002	GIRIMUKTI	2	3205040002	GARUMUKTI	2
3	32.05.34.2003	PANAWA	3	3205040003	PANAWA	2
4	32.05.34.2001	PAKENJENG	4	3205040004	PAKENJENG	2
5	32.05.34.2004	PANANJUNG	5	3205040005	PANANJUNG	2

Catatan :
*) 1. Perkotaan
2. Perdesaan

https://jabar.bps.go.id

PROVINSI : [32] JAWA BARAT
KAB/KOTA : [05] GARUT
KECAMATAN : [050] PAKENJENG

Data Kemendagri			MFD 2021 Semester 2			
No	Kode	Nama Desa	No	Kode	Nama Desa	Status*
1	32.05.33.2012	KARANGSARI	1	3205050001	KARANGSARI	2
2	32.05.33.2003	TANJUNG MULYA	2	3205050002	TANJUNG MULYA	2
3	32.05.33.2002	TANJUNGJAYA	3	3205050003	TANJUNGJAYA	2
4	32.05.33.2010	TEGALGEDE	4	3205050004	TEGALGEDE	2
5	32.05.33.2001	NEGLASARI	5	3205050005	NEGLASARI	2
6	32.05.33.2005	SUKAMULYA	6	3205050006	SUKAMULYA	2
7	32.05.33.2011	DEPOK	7	3205050007	DEPOK	2
8	32.05.33.2006	PASIRLANGU	8	3205050008	PASIRLANGU	2
9	32.05.33.2009	PANYINDANG AN	9	3205050009	PANYINDANG AN	2
10	32.05.33.2004	WANGUNJAYA	10	3205050010	WANGUNJAYA	2
11	32.05.33.2008	JATIWANGI	11	3205050011	JATIWANGI	2
12	32.05.33.2007	TALAGAWANGI	12	3205050012	TALAGAWANGI	2
13	32.05.33.2013	JAYAMEKAR	13	3205050013	JAYAMEKAR	2

Catatan :
*) 1. Perkotaan
2. Perdesaan

https://jabar.bps.go.id

DAFTAR DESA/KELURAHAN

PROVINSI : [32] JAWA BARAT
KAB/KOTA : [05] GARUT
KECAMATAN : [060] CIKELET

Data Kemendagri			MFD 2021 Semester 2			
No	Kode	Nama Desa	No	Kode	Nama Desa	Status*
1	32.05.30.2004	CIGADOG	1	325060001	CIGADOG	2
2	32.05.30.2007	CIJAMBE	2	325060002	CIJAMBE	2
3	32.05.30.2001	CIKELET	3	325060003	CIKELET	2
4	32.05.30.2005	PAMALAYAN	4	325060004	PAMALAYAN	2
5	32.05.30.2002	LINGGAMANIK	5	325060005	LINGGAMANIK	2
6	32.05.30.2006	KARANGSARI	6	325060006	KARANGSARI	2
7	32.05.30.2003	KERTAMUKTI	7	325060007	KERTAMUKTI	2
8	32.05.30.2009	CIROYOM	8	325060008	CIROYOM	2
9	32.05.30.2008	GIRIMUKTI	9	325060009	GIRIMUKTI	2
10	32.05.30.2011	TIPAR	10	325060010	TIPAR	2
11	32.05.30.2010	AWASSAGARA	11	325060011	AWASSAGARA	2

Catatan :
*) 1. Perkotaan
2. Perdesaan

https://jabar.bps.go.id

PROVINSI : [32] JAWA BARAT
KAB/KOTA : [05] GARUT
KECAMATAN : [070] PAMEUNGPEUK

Data Kemendagri			MFD 2021 Semester 2			
No	Kode	Nama Desa	No	Kode	Nama Desa	Status*
1	32.05.27.2002	MANCAGAHAR	1	3205070001	MANCAGAHAR	1
2	32.05.27.2001	PAMEUNG-PEUK	2	3205070002	PAMEUNG-PEUK	1
3	32.05.27.2004	MANDALA KASIH	3	3205070003	MANDALA KASIH	1
4	32.05.27.2007	SINARBAKTI	4	3205070004	SINARBAKTI	2
5	32.05.27.2003	PAAS	5	3205070005	PAAS	1
6	32.05.27.2006	BOJONG	6	3205070006	BOJONG	2
7	32.05.27.2005	JATIMULYA	7	3205070007	JATIMULYA	2
8	32.05.27.2008	BOJONGKIDUL	8	3205070008	BOJONGKIDUL	2

Catatan :
*) 1. Perkotaan
2. Perdesaan

https://jabar.bps.go.id

DAFTAR DESA/KELURAHAN

PROVINSI : [32] JAWA BARAT
KAB/KOTA : [05] GARUT
KECAMATAN : [080] CIBALONG

Data Kemendagri			MFD 2021 Semester 2			
No	Kode	Nama Desa	No	Kode	Nama Desa	Status*
1	32.05.29.2006	MEKARSARI	1	3205080001	MEKARSARI	2
2	32.05.29.2001	KARYASARI	2	3205080002	KARYASARI	2
3	32.05.29.2004	KARYA MUKTI	3	3205080003	KARYA MUKTI	2
4	32.05.29.2005	SAGARA	4	3205080004	SAGARA	2
5	32.05.29.2002	MAROKO	5	3205080005	MAROKO	2
6	32.05.29.2003	SANCANG	6	3205080006	SANCANG	2
7	32.05.29.2007	SIMPANG	7	3205080007	SIMPANG	2
8	32.05.29.2009	CIGARONG-GONG	8	3205080008	CIGARONG-GONG	2
9	32.05.29.2008	MEKARMUKTI	9	3205080009	MEKARMUKTI	2
10	32.05.29.2010	MEKARWANGI	10	3205080010	MEKARWANGI	2
11	32.05.29.2011	NAJATEN	11	3205080011	NAJATEN	2

Catatan :
*) 1. Perkotaan
2. Perdesaan

https://jabar.bps.go.id

PROVINSI : [32] JAWA BARAT
KAB/KOTA : [05] GARUT
KECAMATAN : [090] CISOMPET

Data Kemendagri			MFD 2021 Semester 2			
No	Kode	Nama Desa	No	Kode	Nama Desa	Status*
1	32.05.28.2007	DEPOK	1	3205090001	DEPOK	2
2	32.05.28.2005	SUKANAGARA	2	3205090002	SUKANAGARA	2
3	32.05.28.2002	CIHAURKU NING	3	3205090003	CIHAURKU NING	2
4	32.05.28.2006	CIKONDANG	4	3205090004	CIKONDANG	2
5	32.05.28.2009	JATISARI	5	3205090005	JATISARI	2
6	32.05.28.2001	CISOMPET	6	3205090006	CISOMPET	1
7	32.05.28.2004	SUKAMUKTI	7	3205090007	SUKAMUKTI	2
8	32.05.28.2008	PANYINDANG AN	8	3205090008	PANYINDANG AN	2
9	32.05.28.2003	MARGAMULYA	9	3205090009	MARGAMULYA	2
10	32.05.28.2011	SINDANGSARI	10	3205090010	SINDANGSARI	2
11	32.05.28.2010	NEGLASARI	11	3205090011	NEGLASARI	2

Catatan :
*) 1. Perkotaan
2. Perdesaan

https://jabar.bps.go.id

DAFTAR DESA/KELURAHAN

PROVINSI : [32] JAWA BARAT
KAB/KOTA : [05] GARUT
KECAMATAN : [100] PEUNDEUY

Data Kemendagri			MFD 2021 Semester 2			
No	Kode	Nama Desa	No	Kode	Nama Desa	Status*
1	32.05.26.2004	PANGRUMA-SAN	1	3205100001	PANGRUMA-SAN	2
2	32.05.26.2002	TOBLONG	2	3205100002	TOBLONG	2
3	32.05.26.2005	SUKANAGARA	3	3205100003	SUKANAGARA	2
4	32.05.26.2003	SARIBAKTI	4	3205100004	SARIBAKTI	2
5	32.05.26.2001	PEUNDEUY	5	3205100005	PEUNDEUY	2
6	32.05.26.2006	PURWAJAYA	6	3205100006	PURWAJAYA	2

Catatan :
*) 1. Perkotaan
2. Perdesaan

https://jabar.bps.go.id

PROVINSI : [32] JAWA BARAT
KAB/KOTA : [05] GARUT
KECAMATAN : [110] SINGAJAYA

Data Kemendagri			MFD 2021 Semester 2			
No	Kode	Nama Desa	No	Kode	Nama Desa	Status*
1	32.05.24.2001	SINGAJAYA	1	3205110005	SINGAJAYA	1
2	32.05.24.2007	KARANG AGUNG	2	3205110006	KARANG AGUNG	2
3	32.05.24.2003	MEKARTANI	3	3205110007	MEKARTANI	2
4	32.05.24.2008	CIGINTUNG	4	3205110008	CIGINTUNG	1
5	32.05.24.2005	SUKAWANGI	5	3205110009	SUKAWANGI	2
6	32.05.24.2006	PANCASURA	6	3205110010	PANCASURA	2
7	32.05.24.2004	SUKAMULYA	7	3205110011	SUKAMULYA	2
8	32.05.24.2009	GIRIMUKTI	8	3205110012	GIRIMUKTI	2
9	32.05.24.2002	CIUDIAN	9	3205110013	CIUDIAN	2

https://jabar.bps.go.id

Catatan :
*) 1. Perkotaan
2. Perdesaan

DAFTAR DESA/KELURAHAN

PROVINSI : [32] JAWA BARAT
KAB/KOTA : [05] GARUT
KECAMATAN : [111] CIHURIP

Data Kemendagri			MFD 2021 Semester 2			
No	Kode	Nama Desa	No	Kode	Nama Desa	Status*
1	32.05.25.2002	CISANGKAL	1	3205111001	CISANGKAL	2
2	32.05.25.2004	JAYAMUKTI	2	3205111002	JAYAMUKTI	2
3	32.05.25.2001	CIHURIP	3	3205111003	CIHURIP	2
4	32.05.25.2003	MEKARWANGI	4	3205111004	MEKARWANGI	2

Catatan :
*) 1. Perkotaan
2. Perdesaan

https://jabar.bps.go.id

PROVINSI : [32] JAWA BARAT
KAB/KOTA : [05] GARUT
KECAMATAN : [120] CIKAJANG

Data Kemendagri			MFD 2021 Semester 2			
No	Kode	Nama Desa	No	Kode	Nama Desa	Status*
1	32.05.22.2011	CIPANGRAMATAN	1	3205120001	CIPANGRAMATAN	2
2	32.05.22.2007	MEKARJAYA	2	3205120002	MEKARJAYA	2
3	32.05.22.2004	GIRIJAYA	3	3205120003	GIRIJAYA	2
4	32.05.22.2005	GIRIAWAS	4	3205120004	GIRIAWAS	1
5	32.05.22.2006	CIBODAS	5	3205120005	CIBODAS	1
6	32.05.22.2001	CIKAJANG	6	3205120006	CIKAJANG	1
7	32.05.22.2009	PADASUKA	7	3205120007	PADASUKA	1
8	32.05.22.2003	MEKARSARI	8	3205120008	MEKARSARI	1
9	32.05.22.2002	SIMPANG	9	3205120009	SIMPANG	2
10	32.05.22.2008	CIKANDANG	10	3205120010	CIKANDANG	2
11	32.05.22.2010	MARGAMULYA	11	3205120011	MARGAMULYA	2
12	32.05.22.2012	KARAMAT-WANGI	12	3205120012	KARAMAT-WANGI	2

Catatan :
*) 1. Perkotaan
2. Perdesaan

https://jabar.bps.go.id

DAFTAR DESA/KELURAHAN

PROVINSI : [32] JAWA BARAT
KAB/KOTA : [05] GARUT
KECAMATAN : [130] BANJARWANGI

Data Kemendagri			MFD 2021 Semester 2			
No	Kode	Nama Desa	No	Kode	Nama Desa	Status*
1	32.05.23.2008	DANGIANG	1	3205130001	DANGIANG	2
2	32.05.23.2006	JAYABAKTI	2	3205130002	JAYABAKTI	2
3	32.05.23.2010	BOJONG	3	3205130003	BOJONG	2
4	32.05.23.2001	BANJARWANGI	4	3205130004	BANJARWANGI	1
5	32.05.23.2005	TALAGASARI	5	3205130005	TALAGASARI	2
6	32.05.23.2003	PADAHURIP	6	3205130006	PADAHURIP	2
7	32.05.23.2004	KADONG-DONG	7	3205130007	KADONG-DONG	2
8	32.05.23.2011	WANGUNJAYA	8	3205130008	WANGUNJAYA	2
9	32.05.23.2002	TALAGAJAYA	9	3205130009	TALAGAJAYA	2
10	32.05.23.2009	TANJUNGJAYA	10	3205130010	TANJUNGJAYA	2
11	32.05.23.2007	MULYAJAYA	11	3205130011	MULYAJAYA	2

https://jabar.bps.go.id

Catatan :
*) 1. Perkotaan
2. Perdesaan

PROVINSI : [32] JAWA BARAT
KAB/KOTA : [05] GARUT
KECAMATAN : [140] CILAWU

Data Kemendagri			MFD 2021 Semester 2			
No	Kode	Nama Desa	No	Kode	Nama Desa	Status*
1	32.05.19.2018	SUKAMURNI	1	3205140001	SUKAMURNI	2
2	32.05.19.2014	SUKAMAJU	2	3205140002	SUKAMAJU	2
3	32.05.19.2017	SUKATANI	3	3205140003	SUKATANI	2
4	32.05.19.2007	MEKARSARI	4	3205140004	MEKARSARI	2
5	32.05.19.2013	DAYEUH-MANGGUNG	5	3205140005	DAYEUHMANG-GUNG	2
6	32.05.19.2003	KARYAMEKAR	6	3205140006	KARYAMEKAR	2
7	32.05.19.2001	CILAWU	7	3205140007	CILAWU	1
8	32.05.19.2005	PASANGGRA-HAN	8	3205140008	PASANGGRA-HAN	1
9	32.05.19.2011	MARGALAK-SANA	9	3205140009	MARGALAK-SANA	1
10	32.05.19.2004	DAWUNGSARI	10	3205140010	DAWUNGSARI	2
11	32.05.19.2012	DANGIANG	11	3205140011	DANGIANG	2
12	32.05.19.2002	SUKAMUKTI	12	3205140012	SUKAMUKTI	2
13	32.05.19.2008	MEKARMUKTI	13	3205140013	MEKARMUKTI	2
14	32.05.19.2006	SUKAHATI	14	3205140014	SUKAHATI	2
15	32.05.19.2015	MANGU RAKYAT	15	3205140015	MANGKURAYAT	1
16	32.05.19.2009	DESAKOLOT	16	3205140016	DESAKOLOT	2
17	32.05.19.2016	NGAMPLANG	17	3205140017	NGAMPLANG	1
18	32.05.19.2010	NGAMPLANG-SARI	18	3205140018	NGAMPLANG-SARI	1

Catatan :
*) 1. Perkotaan
2. Perdesaan

https://jabar.bps.go.id

DAFTAR DESA/KELURAHAN

PROVINSI : [32] JAWA BARAT
KAB/KOTA : [05] GARUT
KECAMATAN : [150] BAYONGBONG

Data Kemendagri			MFD 2021 Semester 2			
No	Kode	Nama Desa	No	Kode	Nama Desa	Status*
1	32.05.17.2007	PAMALAYAN	1	3205150006	PAMALAYAN	2
2	32.05.17.2009	CIBURUY	2	3205150007	CIBURUY	1
3	32.05.17.2006	MULYASARI	3	3205150008	MULYASARI	1
4	32.05.17.2001	BAYONGBONG	4	3205150009	BAYONGBONG	1
5	32.05.17.2017	CINISTI	5	3205150010	CINISTI	2
6	32.05.17.2010	CIELA	6	3205150011	CIELA	2
7	32.05.17.2005	KARYAJAYA	7	3205150012	KARYAJAYA	2
8	32.05.17.2002	PANEMBONG	8	3205150013	PANEMBONG	2
9	32.05.17.2016	SUKARAME	9	3205150014	SUKARAME	1
10	32.05.17.2003	HEGARMANAH	10	3205150015	HEGARMANAH	2
11	32.05.17.2015	SIRNAGALIH	11	3205150016	SIRNAGALIH	2
12	32.05.17.2004	SALAKURAY	12	3205150017	SALAKURAY	1
13	32.05.17.2013	SUKASENANG	13	3205150018	SUKASENANG	2
14	32.05.17.2011	CIKEDOKAN	14	3205150019	CIKEDOKAN	1
15	32.05.17.2008	MEKARSARI	15	3205150020	MEKARSARI	1
16	32.05.17.2012	BANJARSARI	16	3205150021	BANJARSARI	1
17	32.05.17.2014	MEKARJAYA	17	3205150022	MEKARJAYA	2
18	32.05.17.2018	SUKAMANAH	18	3205150023	SUKAMANAH	1

Catatan :
*) 1. Perkotaan
2. Perdesaan

https://jabar.bps.go.id

PROVINSI : [32] JAWA BARAT
KAB/KOTA : [05] GARUT
KECAMATAN : [151] CIGEDUG

Data Kemendagri			MFD 2021 Semester 2			
No	Kode	Nama Desa	No	Kode	Nama Desa	Status*
1	32.05.18.2002	BARUSUDA	1	3205151001	BARUSUDA	1
2	32.05.18.2001	CIGEDUG	2	3205151002	CIGEDUG	2
3	32.05.18.2003	SUKAHURIP	3	3205151003	SUKAHURIP	2
4	32.05.18.2004	SINDANGSARI	4	3205151004	SINDANGSARI	2
5	32.05.18.2005	CINTANAGARA	5	3205151005	CINTANAGARA	2

Catatan :
*) 1. Perkotaan
2. Perdesaan

https://jabar.bps.go.id

DAFTAR DESA/KELURAHAN

PROVINSI : [32] JAWA BARAT
KAB/KOTA : [05] GARUT
KECAMATAN : [160] CISURUPAN

Data Kemendagri			MFD 2021 Semester 2			
No	Kode	Nama Desa	No	Kode	Nama Desa	Status*
1	32.05.20.2003	SUKAWARGI	1	3205160001	SUKAWARGI	2
2	32.05.20.2004	SUKATANI	2	3205160002	SUKATANI	2
3	32.05.20.2002	CIDATAR	3	3205160003	CIDATAR	1
4	32.05.20.2009	CISERO	4	3205160004	CISERO	1
5	32.05.20.2001	CISURUPAN	5	3205160005	CISURUPAN	1
6	32.05.20.2010	KARAMAT-WANGI	6	3205160006	KARAMAT-WANGI	1
7	32.05.20.2007	BALEWANGI	7	3205160007	BALEWANGI	1
8	32.05.20.2013	TAMBAKBAYA	8	3205160008	TAMBAKBAYA	2
9	32.05.20.2008	SIRNAJAYA	9	3205160009	SIRNAJAYA	1
10	32.05.20.2014	SIRNAGALIH	10	3205160010	SIRNAGALIH	2
11	32.05.20.2006	PAKUWON	11	3205160011	PAKUWON	1
12	32.05.20.2016	SIMPANGSARI	12	3205160012	SIMPANGSARI	1
13	32.05.20.2015	PANGAUBAN	13	3205160013	PANGAUBAN	2
14	32.05.20.2011	CIPAGANTI	14	3205160014	CIPAGANTI	2
15	32.05.20.2012	PAMULIHAN	15	3205160015	PAMULIHAN	2
16	32.05.20.2005	SITUSARI	16	3205160016	SITUSARI	2
17	32.05.20.2017	CINTAASIH	17	3205160017	CINTAASIH	1

Catatan :
*) 1. Perkotaan
2. Perdesaan

https://jabar.bps.go.id

PROVINSI : [32] JAWA BARAT
KAB/KOTA : [05] GARUT
KECAMATAN : [161] SUKARESMI

Data Kemendagri			MFD 2021 Semester 2			
No	Kode	Nama Desa	No	Kode	Nama Desa	Status*
1	32.05.21.2005	SUKAMULYA	1	3205161001	SUKAMULYA	2
2	32.05.21.2001	SUKARESMI	2	3205161002	SUKARESMI	1
3	32.05.21.2006	PADAMUKTI	3	3205161003	PADAMUKTI	2
4	32.05.21.2002	CINTADAMAI	4	3205161004	CINTADAMAI	2
5	32.05.21.2004	SUKAJAYA	5	3205161005	SUKAJAYA	2
6	32.05.21.2003	MEKARJAYA	6	3205161006	MEKARJAYA	2
7	32.05.21.2007	SUKALILAH	7	3205161007	SUKALILAH	2

Catatan :
*) 1. Perkotaan
2. Perdesaan

https://jabar.bps.go.id

DAFTAR DESA/KELURAHAN

PROVINSI : [32] JAWA BARAT
KAB/KOTA : [05] GARUT
KECAMATAN : [170] SAMARANG

Data Kemendagri			MFD 2021 Semester 2			
No	Kode	Nama Desa	No	Kode	Nama Desa	Status*
1	32.05.07.2008	CISARUA	1	3205170013	CISARUA	2
2	32.05.07.2004	PARAKAN	2	3205170013	PARAKAN	2
3	32.05.07.2012	SUKALAKSANA	3	3205170013	SUKALAKSANA	2
4	32.05.07.2011	SIRNASARI	4	3205170013	SIRNASARI	1
5	32.05.07.2006	CINTAKARYA	5	3205170013	CINTAKARYA	1
6	32.05.07.2009	CINTARASA	6	3205170013	CINTARASA	2
7	32.05.07.2002	CINTARAKYAT	7	3205170013	CINTARAYAT	1
8	32.05.07.2010	CINTAASIH	8	3205170013	CINTAASIH	1
9	32.05.07.2001	SAMARANG	9	3205170013	SAMARANG	1
10	32.05.07.2003	SUKARASA	10	3205170013	SUKARASA	1
11	32.05.07.2005	SUKAKARYA	11	3205170013	SUKAKARYA	2
12	32.05.07.2007	TANJUNG-KARYA	12	3205170013	TANJUNG KARYA	2
13	32.05.07.2013	TANJUNG ANOM	13	3205170013	TANJUNG ANOM	2

Catatan :
*) 1. Perkotaan
2. Perdesaan

https://jabar.bps.go.id

PROVINSI : [32] JAWA BARAT
KAB/KOTA : [05] GARUT
KECAMATAN : [171] PASIRWANGI

Data Kemendagri			MFD 2021 Semester 2			
No	Kode	Nama Desa	No	Kode	Nama Desa	Status*
1	32.05.08.2004	KARYAMEKAR	1	3205171001	KARYAMEKAR	2
2	32.05.08.2011	SARIMUKTI	2	3205171002	SARIMUKTI	2
3	32.05.08.2008	TALAGA	3	3205171003	TALAGA	2
4	32.05.08.2002	PASIRKIAMIS	4	3205171004	PASIRKIAMIS	2
5	32.05.08.2009	PADAMUKTI	5	3205171005	PADAMUKTI	1
6	32.05.08.2006	PADAASIH	6	3205171006	PADAASIH	2
7	32.05.08.2003	PADASUKA	7	3205171007	PADASUKA	1
8	32.05.08.2010	SIRNAJAYA	8	3205171008	SIRNAJAYA	2
9	32.05.08.2012	PADAMULYA	9	3205171009	PADAMULYA	2
10	32.05.08.2001	PASIRWANGI	10	3205171010	PASIRWANGI	2
11	32.05.08.2005	PADAAWAS	11	3205171011	PADAAWAS	2
12	32.05.08.2007	BARUSARI	12	3205171012	BARUSARI	2

Catatan :
*) 1. Perkotaan
2. Perdesaan

https://jabar.bps.go.id

DAFTAR DESA/KELURAHAN

PROVINSI : [32] JAWA BARAT
KAB/KOTA : [05] GARUT
KECAMATAN : [181] TAROGONG KIDUL

Data Kemendagri			MFD 2021 Semester 2			
No	Kode	Nama Desa	No	Kode	Nama Desa	Status*
1	32.05.05.2011	KERSAMENAK	1	3205181001	KERSAMENAK	1
2	32.05.05.2005	CIBUNAR	2	3205181002	CIBUNAR	1
3	32.05.05.2007	SUKABAKTI	3	3205181003	SUKABAKTI	1
4	32.05.05.1009	SUKAKARYA	4	3205181004	SUKAKARYA	1
5	32.05.05.1012	SUKAJAYA	5	3205181005	SUKAJAYA	1
6	32.05.05.1006	JAYAWARAS	6	3205181006	JAYAWARAS	1
7	32.05.05.2004	HAURPANG-GUNG	7	3205181007	HAURPANG-GUNG	1
8	32.05.05.2003	JAYARAGA	8	3205181008	JAYARAGA	1
9	32.05.05.1001	PATARUMAN	9	3205181009	PATARUMAN	1
10	32.05.05.1002	SUKAGALIH	10	3205181010	SUKAGALIH	1
11	32.05.05.2010	MEKARGALIH	11	3205181011	MEKARGALIH	1
12	32.05.05.2008	TAROGONG	12	3205181012	TAROGONG	1

Catatan :
*) 1. Perkotaan
2. Perdesaan

https://jabar.bps.go.id

PROVINSI : [32] JAWA BARAT
KAB/KOTA : [05] GARUT
KECAMATAN : [182] TAROGONG KALER

Data Kemendagri			MFD 2021 Semester 2			
No	Kode	Nama Desa	No	Kode	Nama Desa	Status*
1	32.05.04.2006	SIRNAJAYA	1	3205182001	SIRNAJAYA	2
2	32.05.04.2010	MEKARWANGI	2	3205182002	MEKARWANGI	1
3	32.05.04.2001	SUKAJADI	3	3205182003	SUKAJADI	2
4	32.05.04.2005	SUKAWANGI	4	3205182004	SUKAWANGI	2
5	32.05.04.2013	PANJIWANGI	5	3205182005	PANJIWANGI	2
6	32.05.04.2008	MEKARJAYA	6	3205182006	MEKARJAYA	2
7	32.05.04.2004	RANCABANGO	7	3205182007	RANCABANGO	1
8	32.05.04.2009	LANGENSARI	8	3205182008	LANGENSARI	1
9	32.05.04.2002	CIMANGAN TEN	9	3205182009	CIMANGAN TEN	1
10	32.05.04.2003	JATI	10	3205182010	JATI	1
11	32.05.04.2007	TANJUNG KAMUNING	11	3205182011	TANJUNG KAMUNING	1
12	32.05.04.1012	PANANJUNG	12	3205182012	PANANJUNG	1
13	32.05.04.2011	PASAWAHAN	13	3205182013	PASAWAHAN	1

Catatan :
*) 1. Perkotaan
2. Perdesaan

https://jabar.bps.go.id

DAFTAR DESA/KELURAHAN

PROVINSI : [32] JAWA BARAT
KAB/KOTA : [05] GARUT
KECAMATAN : [190] GARUT KOTA

Data Kemendagri			MFD 2021 Semester 2			
No	Kode	Nama Desa	No	Kode	Nama Desa	Status*
1	32.05.01.1003	MARGAWATI	1	3205190001	MARGAWATI	1
2	32.05.01.1010	SUKANEGLA	2	3205190002	SUKANEGLA	1
3	32.05.01.1011	CIMUNCANG	3	3205190003	CIMUNCANG	2
4	32.05.01.1002	KOTAWETAN	4	3205190004	KOTAWETAN	1
5	32.05.01.1001	KOTAKULON	5	3205190005	KOTAKULON	1
6	32.05.01.1005	MUARA SANDING	6	3205190006	MUARA SANDING	1
7	32.05.01.1008	PAMINGGIR	7	3205190007	PAMINGGIR	1
8	32.05.01.1009	REGOL	8	3205190008	REGOL	1
9	32.05.01.1007	CIWALEN	9	3205190009	CIWALEN	1
10	32.05.01.1004	PAKUWON	10	3205190010	PAKUWON	1
11	32.05.01.1006	SUKAMANTRI	11	3205190011	SUKAMANTRI	1

Catatan :
*) 1. Perkotaan
2. Perdesaan

https://jabar.bps.go.id

PROVINSI : [32] JAWA BARAT
KAB/KOTA : [05] GARUT
KECAMATAN : [200] KARANGPAWITAN

Data Kemendagri			MFD 2021 Semester 2			
No	Kode	Nama Desa	No	Kode	Nama Desa	Status*
1	32.05.02.2013	LEBAKAGUNG	1	3205200001	LEBAKAGUNG	2
2	32.05.02.2007	SUCI	2	3205200002	SUCI	1
3	32.05.02.1002	LEBAKJAYA	3	3205200003	LEBAKJAYA	1
4	32.05.02.2018	TANJUNGSARI	4	3205200004	TANJUNGSARI	1
5	32.05.02.2009	GODOG	5	3205200005	GODOG	1
6	32.05.02.2015	SINDANGGALIH	6	3205200006	SINDANGGALIH	1
7	32.05.02.2012	SINDANGPALAY	7	3205200007	SINDANGPALAY	2
8	32.05.02.2004	KARANG PAWITAN	8	3205200008	KARANG PAWITAN	1
9	32.05.02.2005	SITUGEDE	9	3205200009	SITUGEDE	1
10	32.05.02.2010	SITUSARI	10	3205200010	SITUSARI	1
11	32.05.02.2020	SITUJAYA	11	3205200011	SITUJAYA	1
12	32.05.02.2019	SITUSAEUR	12	3205200012	SITUSAEUR	1
13	32.05.02.2011	KARANGSARI	13	3205200013	KARANGSARI	1
14	32.05.02.2006	CIMURAH	14	3205200014	CIMURAH	1
15	32.05.02.2017	SINDANGLAYA	15	3205200015	SINDANGLAYA	1
16	32.05.02.2016	MEKARSARI	16	3205200016	MEKARSARI	2
17	32.05.02.2008	JATISARI	17	3205200017	JATISARI	1
18	32.05.02.1003	KARANGMULYA	18	3205200018	KARANGMULYA	1
19	32.05.02.1001	SUCI KALER	19	3205200019	SUCIKALER	1
20	32.05.02.1014	LENGKONGJAYA	20	3205200020	LENGKONGJAYA	1

https://jabar.bps.go.id

Catatan :
*) 1. Perkotaan
2. Perdesaan

DAFTAR DESA/KELURAHAN

PROVINSI : [32] JAWA BARAT
KAB/KOTA : [05] GARUT
KECAMATAN : [210] WANARAJA

Data Kemendagri			MFD 2021 Semester 2			
No	Kode	Nama Desa	No	Kode	Nama Desa	Status*
1	32.05.03.2007	SUKAMENAK	1	3205210005	SUKAMENAK	2
2	32.05.03.2015	SINDANGME-KAR	2	3205210007	SINDANGME-KAR	2
3	32.05.03.2008	SINDANGRATU	3	3205210008	SINDANGRATU	2
4	32.05.03.2003	CINUNUK	4	3205210012	CINUNUK	1
5	32.05.03.2002	WANAMEKAR	5	3205210013	WANAMEKAR	1
6	32.05.03.2001	WANARAJA	6	3205210014	WANARAJA	1
7	32.05.03.2019	WANASARI	7	3205210015	WANASARI	1
8	32.05.03.2011	WANAJAYA	8	3205210016	WANAJAYA	1
9	32.05.03.2024	SINDANGPRA-BU	9	3205210017	SINDANGPRA-BU	2

Catatan :
*) 1. Perkotaan
2. Perdesaan

https://jabar.bps.go.id

PROVINSI : [32] JAWA BARAT
KAB/KOTA : [05] GARUT
KECAMATAN : [211] SUCINARAJA

Data Kemendagri			MFD 2021 Semester 2			
No	Kode	Nama Desa	No	Kode	Nama Desa	Status*
1	32.05.42.2006	LINGGAMUKTI	1	3205211001	LINGGAMUKTI	2
2	32.05.42.2007	SUKALAKSANA	2	3205211002	SUKALAKSANA	2
3	32.05.42.2005	CIGADOG	3	3205211003	CIGADOG	2
4	32.05.42.2003	TENJONAGARA	4	3205211004	TENJONAGARA	2
5	32.05.42.2002	SUKARATU	5	3205211005	SUKARATU	2
6	32.05.42.2004	TEGALPAN-JANG	6	3205211006	TEGALPAN-JANG	2
7	32.05.42.2001	SADANG	7	3205211007	SADANG	1

Catatan :
*) 1. Perkotaan
2. Perdesaan

https://jabar.bps.go.id

DAFTAR DESA/KELURAHAN

PROVINSI : [32] JAWA BARAT
KAB/KOTA : [05] GARUT
KECAMATAN : [212] PANGATIKAN

Data Kemendagri			MFD 2021 Semester 2			
No	Kode	Nama Desa	No	Kode	Nama Desa	Status*
1	32.05.41.2004	SUKAHURIP	1	3205212001	SUKAHURIP	2
2	32.05.41.2003	BABAKANLOA	2	3205212002	BABAKANLOA	1
3	32.05.41.2007	SUKARASA	3	3205212003	SUKARASA	1
4	32.50.41.2002	CIMARAGAS	4	3205212004	CIMARAGAS	1
5	32.05.41.2006	CIHUNI	5	3205212005	CIHUNI	1
6	32.05.41.2001	CITANGTU	6	3205212006	CITANGTU	1
7	32.05.41.2008	KARANGSARI	7	3205212007	KARANGSARI	1
8	32.05.41.2005	SUKAMULYA	8	3205212008	SUKAMULYA	1

Catatan :
*) 1. Perkotaan
2. Perdesaan

https://jabar.bps.go.id

PROVINSI : [32] JAWA BARAT
KAB/KOTA : [05] GARUT
KECAMATAN : [220] SUKAWENING

Data Kemendagri			MFD 2021 Semester 2			
No	Kode	Nama Desa	No	Kode	Nama Desa	Status*
1	32.05.15.2008	PASANGGRA-HAN	1	3205220001	PASANGGRA-HAN	1
2	32.05.15.2002	SUKAMUKTI	2	3205220006	SUKAMUKTI	1
3	32.05.15.2003	MEKARLUYU	3	3205220007	MEKARLUYU	2
4	32.05.15.2001	SUKAWENING	4	3205220008	SUKAWENING	1
5	32.05.15.2005	SUDALARANG	5	3205220009	SUDALARANG	2
6	32.05.15.2009	MARIPARI	6	3205220010	MARIPARI	2
7	32.05.15.2007	SUKAHAJI	7	3205220011	SUKAHAJI	2
8	32.05.15.2006	SUKASONO	8	3205220012	SUKASONO	2
9	32.05.15.2004	SUKALUYU	9	3205220013	SUKALUYU	2
10	32.05.15.2010	MEKARWANGI	10	3205220014	MEKARWANGI	2
11	32.05.15.2011	MEKARHURIP	11	3205220015	MEKARHURIP	2

Catatan :
*) 1. Perkotaan
2. Perdesaan

https://jabar.bps.go.id

DAFTAR DESA/KELURAHAN

PROVINSI : [32] JAWA BARAT
KAB/KOTA : [05] GARUT
KECAMATAN : [221] KARANG TENGAH

Data Kemendagri			MFD 2021 Semester 2			
No	Kode	Nama Desa	No	Kode	Nama Desa	Status*
1	32.05.16.2004	SINDANGGA-LIH	1	3205221001	SINDANGGA-LIH	2
2	32.05.16.2003	CINTA	2	3205221002	CINTA	2
3	32.05.16.2002	CINTAMANIK	3	3205221003	CINTAMANIK	2
4	32.05.16.2001	CARINGIN	4	3205221004	CARINGIN	2

Catatan :
*) 1. Perkotaan
2. Perdesaan

https://jabar.bps.go.id

PROVINSI : [32] JAWA BARAT
KAB/KOTA : [05] GARUT
KECAMATAN : [230] BANYURESMI

Data Kemendagri			MFD 2021 Semester 2			
No	Kode	Nama Desa	No	Kode	Nama Desa	Status*
1	32.05.06.2005	SUKARAJA	1	3205230003	SUKARAJA	2
2	32.05.06.2008	SUKAKARYA	2	3205230004	SUKAKARYA	2
3	32.05.06.2009	PAMEKARSARI	3	3205230005	PAMEKARSARI	2
4	32.05.06.2004	SUKASENANG	4	3205230006	SUKASENANG	1
5	32.05.06.2003	SUKARATU	5	3205230007	SUKARATU	1
6	32.05.06.2006	CIPICUNG	6	3205230008	CIPICUNG	2
7	32.05.06.2011	BAGENDIT	7	3205230009	BAGENDIT	1
8	32.05.06.2014	SUKAMUKTI	8	3205230010	SUKAMUKTI	2
9	32.05.06.2001	BANYURESMI	9	3205230011	BANYURESMI	1
10	32.05.06.2010	BINAKARYA	10	3205230012	BINAKARYA	2
11	32.05.06.2007	DANGDEUR	11	3205230013	DANGDEUR	2
12	32.05.06.2013	KARYASARI	12	3205230014	KARYASARI	2
13	32.05.06.2012	KARYAMUKTI	13	3205230015	KARYAMUKTI	1
14	32.05.06.2002	CIMAREME	14	3205230016	CIMAREME	2
15	32.05.06.2015	SUKALAKSANA	15	3205230017	SUKALAKSANA	2

Catatan :
*) 1. Perkotaan
2. Perdesaan

https://jabar.bps.go.id

DAFTAR DESA/KELURAHAN

PROVINSI : [32] JAWA BARAT
KAB/KOTA : [05] GARUT
KECAMATAN : [240] LELES

Data Kemendagri			MFD 2021 Semester 2			
No	Kode	Nama Desa	No	Kode	Nama Desa	Status*
1	32.05.09.2012	DANO	1	3205240001	DANO	2
2	32.05.09.2003	JANGKURANG	2	3205240002	JANGKURANG	2
3	32.05.09.2005	LEMBANG	3	3205240003	LEMBANG	2
4	32.05.09.2010	CIPANCAR	4	3205240004	CIPANCAR	2
5	32.05.09.2008	KANDANG-MUKTI	5	3205240005	KANDANG-MUKTI	2
6	32.05.09.2002	CIBURIAL	6	3205240006	CIBURIAL	2
7	32.05.09.2007	SALAMNUNG-GAL	7	3205240007	SALAMNUNG-GAL	1
8	32.05.09.2001	LELES	8	3205240008	LELES	1
9	32.05.09.2011	HARUMAN	9	3205240009	HARUMAN	1
10	32.05.09.2009	MARGALUYU	10	3205240010	MARGALUYU	2
11	32.05.09.2006	CANGKUANG	11	3205240011	CANGKUANG	2
12	32.05.09.2004	SUKARAME	12	3205240012	SUKARAME	2

Catatan :
*) 1. Perkotaan
2. Perdesaan

https://jabar.bps.go.id

PROVINSI : [32] JAWA BARAT
KAB/KOTA : [05] GARUT
KECAMATAN : [250] LEUWIGOONG

Data Kemendagri			MFD 2021 Semester 2			
No	Kode	Nama Desa	No	Kode	Nama Desa	Status*
1	32.05.11.2004	MARGAHAYU	1	3205250001	MARGAHAYU	2
2	32.05.11.2003	MARGACINTA	2	3205250002	MARGACINTA	2
3	32.05.11.2005	DUNGUSIKU	3	3205250003	DUNGUSIKU	1
4	32.05.11.2006	TAMBAK SARI	4	3205250004	TAMBAK SARI	2
5	32.05.11.2008	KARANGSARI	5	3205250005	KARANGSARI	1
6	32.05.11.2002	KARANGAN-YAR	6	3205250006	KARANGAN-YAR	2
7	32.05.11.2007	SINDANGSARI	7	3205250007	SINDANGSARI	1
8	32.05.11.2001	LEUWIGOONG	8	3205250008	LEUWIGOONG	1

Catatan :
*) 1. Perkotaan
2. Perdesaan

https://jabar.bps.go.id

DAFTAR DESA/KELURAHAN

PROVINSI : [32] JAWA BARAT
KAB/KOTA : [05] GARUT
KECAMATAN : [260] CIBATU

Data Kemendagri			MFD 2021 Semester 2			
No	Kode	Nama Desa	No	Kode	Nama Desa	Status*
1	32.05.12.2001	CIBATU	1	3205260001	CIBATU	1
2	32.05.12.2005	KERTAJAYA	2	3205260002	KERTAJAYA	1
3	32.05.12.2011	WANAKERTA	3	3205260003	WANAKERTA	1
4	32.05.12.2008	KARYAMUKTI	4	3205260004	KARYAMUKTI	2
5	32.05.12.2007	PADASUKA	5	3205260005	PADASUKA	1
6	32.05.12.2010	KERESEK	6	3205260006	KERESEK	1
7	32.05.12.2003	CIBUNAR	7	3205260007	CIBUNAR	2
8	32.05.12.2006	SUKALILAH	8	3205260008	SUKALILAH	1
9	32.05.12.2009	GIRIMUKTI	9	3205260009	GIRIMUKTI	2
10	32.05.12.2002	MEKARSARI	10	3205260010	MEKARSARI	1
11	32.05.12.2004	SINDANGSUKA	11	3205260011	SINDANGSUKA	2

Catatan :
*) 1. Perkotaan
2. Perdesaan

https://jabar.bps.go.id

PROVINSI : [32] JAWA BARAT
KAB/KOTA : [05] GARUT
KECAMATAN : [261] KERSAMANAH

Data Kemendagri			MFD 2021 Semester 2			
No	Kode	Nama Desa	No	Kode	Nama Desa	Status*
1	32.05.13.2005	SUKAMAJU	1	3205261001	SUKAMAJU	2
2	32.05.13.2004	GIRIJAYA	2	3205261002	GIRIJAYA	2
3	32.05.13.2001	KERSAMANAH	3	3205261003	KERSAMANAH	1
4	32.05.13.2002	NANJUNGJAYA	4	3205261004	NANJUNGJAYA	1
5	32.05.13.2003	SUKAMERANG	5	3205261005	SUKAMERANG	2
6	32.05.13.2006	MEKARRAYA	6	3205261006	MEKARRAYA	2

Catatan :
*) 1. Perkotaan
2. Perdesaan

https://jabar.bps.go.id

DAFTAR DESA/KELURAHAN

PROVINSI : [32] JAWA BARAT
KAB/KOTA : [05] GARUT
KECAMATAN : [270] CIBIUK

Data Kemendagri			MFD 2021 Semester 2			
No	Kode	Nama Desa	No	Kode	Nama Desa	Status*
1	32.05.40.2001	CIPAREUAN	1	3205270001	CIPAREUAN	1
2	32.05.40.2002	CIBIUK KIDUL	2	3205270002	CIBIUK KIDUL	1
3	32.05.40.2003	CIBIUK KALER	3	3205270003	CIBIUK KALER	2
4	32.05.40.2004	MAJASARI	4	3205270004	MAJASARI	1
5	32.05.40.2003	LINGKUNG PASIR	5	3205270005	LINGKUNG PASIR	2

Catatan :
*) 1. Perkotaan
2. Perdesaan

https://jabar.bps.go.id

PROVINSI : [32] JAWA BARAT
KAB/KOTA : [05] GARUT
KECAMATAN : [280] KADUNGORA

Data Kemendagri			MFD 2021 Semester 2			
No	Kode	Nama Desa	No	Kode	Nama Desa	Status*
1	32.05.10.2014	RANCASALAK	1	3205280001	RANCASALAK	2
2	32.05.10.2005	MANDALASARI	2	3205280002	MANDALASARI	2
3	32.05.10.2011	HEGARSARI	3	3205280003	HEGARSARI	2
4	32.05.10.2010	TALAGASARI	4	3205280004	TALAGASARI	1
5	32.05.10.2008	KARANG MULYA	5	3205280005	KARANG MULYA	1
6	32.05.10.2013	KARANG TENGAH	6	3205280006	KARANG TENGAH	1
7	32.05.10.2002	GANDAMEKAR	7	3205280007	GANDAMEKAR	1
8	32.05.10.2001	KADUNGORA	8	3205280008	KADUNGORA	1
9	32.05.10.2012	NEGLASARI	9	3205280009	NEGLASARI	2
10	32.05.10.2003	CIKEMBULAN	10	3205280010	CIKEMBULAN	2
11	32.05.10.2004	CISAAT	11	3205280011	CISAAT	2
12	32.05.10.2007	MEKARBAKTI	12	3205280012	MEKARBAKTI	2
13	32.05.10.2006	TANGGULUN	13	3205280013	TANGGULUN	2
14	32.05.10.2009	HARUMAN-SARI	14	3205280014	HARUMAN-SARI	1

Catatan :
*) 1. Perkotaan
2. Perdesaan

https://jabar.bps.go.id

DAFTAR DESA/KELURAHAN

PROVINSI : [32] JAWA BARAT
KAB/KOTA : [05] GARUT
KECAMATAN : [290] BLUBUR LIMBANGAN

Data Kemendagri			MFD 2021 Semester 2			
No	Kode	Nama Desa	No	Kode	Nama Desa	Status*
1	32.05.38.2005	CIJOLANG	1	3205290002	CIJOLANG	2
2	32.05.38.2011	CIGAGADE	2	3205290003	CIGAGADE	2
3	32.05.38.2008	PASIRWARU	3	3205290004	PASIRWARU	2
4	32.05.38.2002	LIMBANGAN-BARAT	4	3205290005	LIMBANGAN-BARAT	1
5	32.05.38.2001	LIMBANGAN TENGAH	5	3205290006	LIMBANGAN TENGAH	1
6	32.05.38.2012	LIMBANGAN TIMUR	6	3205290007	LIMBANGAN TIMUR	1
7	32.05.38.2013	DUNGUSWIRU	7	3205290008	DUNGUSWIRU	1
8	32.05.38.2003	GALIHPAKU-WON	8	3205290009	GALIHPAKU-WON	1
9	32.05.38.2006	NEGLASARI	9	3205290010	NEGLASARI	2
10	32.05.38.2004	SURABAYA	10	3205290011	SURABAYA	2
11	32.05.38.2010	CIWANGI	11	3205290012	CIWANGI	2
12	32.05.38.2014	PANGEUREU NAN	12	3205290013	PANGEUREU NAN	2
13	32.05.38.2009	SIMPEN KIDUL	13	3205290014	SIMPEN KIDUL	2
14	32.05.38.2007	SIMPEN KALER	14	3205290015	SIMPEN KALER	2

Catatan :
*) 1. Perkotaan
2. Perdesaan

https://jabar.bps.go.id

PROVINSI : [32] JAWA BARAT
KAB/KOTA : [05] GARUT
KECAMATAN : [300] SELAAWI

Data Kemendagri			MFD 2021 Semester 2			
No	Kode	Nama Desa	No	Kode	Nama Desa	Status*
1	32.05.39.2003	CIGAWIR	1	3205300001	CIGAWIR	2
2	32.05.39.2002	PUTRAJAWA	2	3205300002	PUTRAJAWA	2
3	32.05.39.2006	MEKARSARI	3	3205300003	MEKARSARI	1
4	32.05.39.2001	SELAAWI	4	3205300004	SELAAWI	1
5	32.05.39.2005	CIRAPUHAN	5	3205300005	CIRAPUHAN	1
6	32.05.39.2007	SAMIDA	6	3205300006	SAMIDA	1
7	32.05.39.2004	PELITAASIH	7	3205300007	PELITAASIH	2

Catatan :
*) 1. Perkotaan
2. Perdesaan

https://jabar.bps.go.id

DAFTAR DESA/KELURAHAN

PROVINSI : [32] JAWA BARAT
KAB/KOTA : [05] GARUT
KECAMATAN : [310] MALANGBONG

Data Kemendagri			MFD 2021 Semester 2			
No	Kode	Nama Desa	No	Kode	Nama Desa	Status*
1	32.05.14.2017	KUTANAGARA	1	3205310001	KUTANAGARA	2
2	32.05.14.2018	SANDING	2	3205310002	SANDING	1
3	32.05.14.2002	KARANGMULYA	3	3205310003	KARANGMULYA	2
4	32.05.14.2012	CINAGARA	4	3205310004	CINAGARA	2
5	32.05.14.2004	CIKARAG	5	3205310005	CIKARAG	2
6	32.05.14.2008	CAMPAKA	6	3205310006	CAMPAKA	1
7	32.05.14.2010	SUKAMANAH	7	3205310007	SUKAMANAH	1
8	32.05.14.2019	CIHAURKU NING	8	3205310008	CIHAURKU NING	1
9	32.05.14.2014	CITERAS	9	3205310009	CITERAS	1
10	32.05.14.2009	LEWOBARU	10	3205310010	LEWOBARU	1
11	32.05.14.2013	SUKARATU	11	3205310011	SUKARATU	1
12	32.05.14.2015	SUKARASA	12	3205310012	SUKARASA	2
13	32.05.14.2003	CIBUNAR	13	3205310013	CIBUNAR	2
14	32.05.14.2001	MALANGBONG	14	3205310014	MALANGBONG	1
15	32.05.14.2007	CISITU	15	3205310015	CISITU	1
16	32.05.14.2005	SAKAWAYANA	16	3205310016	SAKAWAYANA	2
17	32.05.14.2016	SEKARWANGI	17	3205310017	SEKARWANGI	2
18	32.05.14.2006	MEKARASIH	18	3205310018	MEKARASIH	2
19	32.05.14.2011	CILAMPUYANG	19	3205310019	CILAMPUYANG	2
20	32.05.14.2023	MEKAR MULYA	20	3205310020	MEKAR MULYA	2

https://jabar.bps.go.id

PROVINSI : [32] JAWA BARAT
KAB/KOTA : [05] GARUT
KECAMATAN : [310] MALANGBONG

Data Kemendagri			MFD 2021 Semester 2			
No	Kode	Nama Desa	No	Kode	Nama Desa	Status*
(lanjutan...)						
21	32.05.14.2020	BARUDUA	21	3205310021	BARUDUA	2
22	32.05.14.2022	BUNISARI	22	3205310022	BUNISARI	2
23	32.05.14.2021	SUKAJAYA	23	3205310023	SUKAJAYA	2
24	32.05.14.2024	GIRIMAKMUR	24	3205310024	GIRIMAKMUR	1

Catatan :
*) 1. Perkotaan
2. Perdesaan

https://jabar.bps.go.id

https://jabar.bps.go.id

KABUPATEN TASIKMALAYA

https://jabar.bps.go.id

https://jabar.bps.go.id

PROVINSI : [32] JAWA BARAT
KAB/KOTA : [06] TASIKMALAYA

Data Kemendagri			MFD 2021 Semester 2		
No	Kode	Nama Kecamatan	No	Kode	Nama Kecamatan
1	32.06.01	CIPATUJAH	1	3206010	CIPATUJAH
2	32.06.02	KARANGNUNGGAL	2	3206020	KARANGNUNGGAL
3	32.06.03	CIKALONG	3	3206030	CIKALONG
4	32.06.04	PANCATENGAH	4	3206040	PANCATENGAH
5	32.06.05	CIKATOMAS	5	3206050	CIKATOMAS
6	32.06.06	CIBALONG	6	3206060	CIBALONG
7	32.06.07	PARUNGPONTENG	7	3206061	PARUNGPONTENG
8	32.06.08	BANTARKALONG	8	3206070	BANTARKALONG
9	32.06.09	BOJONGASIH	9	3206071	BOJONGASIH
10	32.06.10	CULAMEGA	10	3206072	CULAMEGA
11	32.06.11	BOJONGGAMBIR	11	3206080	BOJONGGAMBIR
12	32.06.12	SODONGHILIR	12	3206090	SODONGHILIR
13	32.06.13	TARAJU	13	3206100	TARAJU
14	32.06.14	SALAWU	14	3206110	SALAWU
15	32.06.15	PUSPAHIANG	15	3206111	PUSPAHIANG
16	32.06.16	TANJUNGJAYA	16	3206120	TANJUNGJAYA
17	32.06.17	SUKARAJA	17	3206130	SUKARAJA
18	32.06.18	SALOPA	18	3206140	SALOPA
19	32.06.19	JATIWARAS	19	3206141	JATIWARAS
20	32.06.20	CINEAM	20	3206150	CINEAM
21	32.06.21	KARANG JAYA	21	3206151	KARANG JAYA
22	32.06.22	MANONJAYA	22	3206160	MANONJAYA
23	32.06.23	GUNUNG TANJUNG	23	3206161	GUNUNG TANJUNG

https://jabar.bps.go.id

DAFTAR KECAMATAN

PROVINSI : [32] JAWA BARAT
KAB/KOTA : [06] TASIKMALAYA

Data Kemendagri			MFD 2021 Semester 2		
No	Kode	Nama Kecamatan	No	Kode	Nama Kecamatan
24	32.06.24	SINGAPARNA	24	3206190	SINGAPARNA
25	32.06.25	SUKARAME	25	3206191	SUKARAME
26	32.06.26	MANGUNREJA	26	3206192	MANGUNREJA
27	32.06.27	CIGALONTANG	27	3206200	CIGALONTANG
28	32.06.28	LEUWISARI	28	3206210	LEUWISARI
29	32.06.29	SARIWANGI	29	3206211	SARIWANGI
30	32.06.30	PADAKEMBANG	30	3206212	PADAKEMBANG
31	32.06.31	SUKARATU	31	3206221	SUKARATU
32	32.06.32	CISAYONG	32	3206230	CISAYONG
33	32.06.33	SUKAHENING	33	3206231	SUKAHENING
34	32.06.34	RAJAPOLAH	34	3206240	RAJAPOLAH
35	32.06.35	JAMANIS	35	3206250	JAMANIS
36	32.06.36	CIAWI	36	3206260	CIAWI
37	32.06.37	KADIPATEN	37	3206261	KADIPATEN
38	32.06.38	PAGERAGEUNG	38	3206270	PAGERAGEUNG
39	32.06.39	SUKARESIK	39	3206271	SUKARESIK

https://jabar.bps.go.id

JUMLAH DESA/KELURAHAN PER KECAMATAN

PROVINSI : [32] JAWA BARAT
KAB/KOTA : [06] TASIKMALAYA

Data Kemendagri				MFD 2021 Semester 2			
No	Kode	Nama Kecamatan	Jml Desa	No	Kode	Nama Kecamatan	Jml Desa
1	32.06.01	CIPATUJAH	15	1	3206010	CIPATUJAH	15
2	32.06.02	KARANGNUNG-GAL	14	2	3206020	KARANGNUNG-GAL	14
3	32.06.03	CIKALONG	13	3	3206030	CIKALONG	13
4	32.06.04	PANCATENGAH	11	4	3206040	PANCATENGAH	11
5	32.06.05	CIKATOMAS	9	5	3206050	CIKATOMAS	9
6	32.06.06	CIBALONG	6	6	3206060	CIBALONG	6
7	32.06.07	PARUNGPON-TENG	8	7	3206061	PARUNGPON-TENG	8
8	32.06.08	BANTARKALONG	8	8	3206070	BANTARKALONG	8
9	32.06.09	BOJONGASIH	6	9	3206071	BOJONGASIH	6
10	32.06.10	CULAMEGA	5	10	3206072	CULAMEGA	5
11	32.06.11	BOJONGGAMBIR	10	11	3206080	BOJONGGAMBIR	10
12	32.06.12	SODONGHILIR	12	12	3206090	SODONGHILIR	12
13	32.06.13	TARAJU	9	13	3206100	TARAJU	9
14	32.06.14	SALAWU	12	14	3206110	SALAWU	12
15	32.06.15	PUSPAHIANG	8	15	3206111	PUSPAHIANG	8
16	32.06.16	TANJUNGJAYA	7	16	3206120	TANJUNGJAYA	7
17	32.06.17	SUKARAJA	8	17	3206130	SUKARAJA	8
18	32.06.18	SALOPA	9	18	3206140	SALOPA	9
19	32.06.19	JATIWARAS	11	19	3206141	JATIWARAS	11
20	32.06.20	CINEAM	10	20	3206150	CINEAM	10

https://jabar.bps.go.id

JUMLAH DESA/KELURAHAN PER KECAMATAN

PROVINSI : [32] JAWA BARAT
KAB/KOTA : [06] TASIKMALAYA

Data Kemendagri				MFD 2021 Semester 2			
No	Kode	Nama Kecamatan	Jml Desa	No	Kode	Nama Kecamatan	Jml Desa
21	32.06.21	KARANG JAYA	4	21	3206151	KARANG JAYA	4
22	32.06.22	MANONJAYA	12	22	3206160	MANONJAYA	12
23	32.06.23	GUNUNG TAN-JUNG	7	23	3206161	GUNUNG TAN-JUNG	7
24	32.06.24	SINGAPARNA	10	24	3206190	SINGAPARNA	10
25	32.06.25	SUKARAME	6	25	3206191	SUKARAME	6
26	32.06.26	MANGUNREJA	6	26	3206192	MANGUNREJA	6
27	32.06.27	CIGALONTANG	16	27	3206200	CIGALONTANG	16
28	32.06.28	LEUWISARI	7	28	3206210	LEUWISARI	7
29	32.06.29	SARIWANGI	8	29	3206211	SARIWANGI	8
30	32.06.30	PADAKEMBANG	5	30	3206212	PADAKEMBANG	5
31	32.06.31	SUKARATU	8	31	3206221	SUKARATU	8
32	32.06.32	CISAYONG	13	32	3206230	CISAYONG	13
33	32.06.33	SUKAHENING	7	33	3206231	SUKAHENING	7
34	32.06.34	RAJAPOLAH	8	34	3206240	RAJAPOLAH	8
35	32.06.35	JAMANIS	8	35	3206250	JAMANIS	8
36	32.06.36	CIAWI	11	36	3206260	CIAWI	11
37	32.06.37	KADIPATEN	6	37	3206261	KADIPATEN	6
38	32.06.38	PAGERAGEUNG	10	38	3206270	PAGERAGEUNG	10
39	32.06.39	SUKARESIK	8	39	3206271	SUKARESIK	8

https://jabar.bps.go.id

PROVINSI : [32] JAWA BARAT
KAB/KOTA : [06] TASIKMALAYA
KECAMATAN : [010] CIPATUJAH

Data Kemendagri			MFD 2021 Semester 2			
No	Kode	Nama Desa	No	Kode	Nama Desa	Status*
1	32.06.01.2001	CIHERAS	1	3206010001	CIHERAS	2
2	32.06.01.2010	CIPANAS	2	3206010002	CIPANAS	2
3	32.06.01.2012	CIANDUM	3	3206010003	CIANDUM	2
4	32.06.01.2002	CIPATUJAH	4	3206010004	CIPATUJAH	2
5	32.06.01.2003	SINDANGKER-TA	5	3206010005	SINDANGKER-TA	2
6	32.06.01.2004	CIKAWUNG GADING	6	3206010006	CIKAWUNG GADING	2
7	32.06.01.2011	KERTASARI	7	3206010007	KERTASARI	2
8	32.06.01.2014	PADAWARAS	8	3206010008	PADAWARAS	2
9	32.06.01.2006	DARAWATI	9	3206010009	DARAWATI	2
10	32.06.01.2005	BANTARKA-LONG	10	3206010010	BANTARKA-LONG	2
11	32.06.01.2009	TOBONGJAYA	11	3206010011	TOBONGJAYA	2
12	32.06.01.2013	NANGELASARI	12	3206010012	NANGELASARI	2
13	32.06.01.2007	NAGROG	13	3206010013	NAGROG	2
14	32.06.01.2008	PAMEUTINGAN	14	3206010014	PAMEUTINGAN	2
15	32.06.01.2015	SUKAHURIP	15	3206010015	SUKAHURIP	2

Catatan :
*) 1. Perkotaan
2. Perdesaan

https://jabar.bps.go.id

DAFTAR DESA/KELURAHAN

PROVINSI : [32] JAWA BARAT
KAB/KOTA : [06] TASIKMALAYA
KECAMATAN : [020] KARANGNUNGGAL

Data Kemendagri			MFD 2021 Semester 2			
No	Kode	Nama Desa	No	Kode	Nama Desa	Status*
1	32.06.02.2001	CIDADAP	1	3206020001	CIDADAP	2
2	32.06.02.2014	KUJANG	2	3206020002	KUJANG	2
3	32.06.02.2013	SARIMUKTI	3	3206020003	SARIMUKTI	2
4	32.06.02.2002	CIAWI	4	3206020004	CIAWI	2
5	32.06.02.2012	CIKAPINIS	5	3206020005	CIKAPINIS	2
6	32.06.02.2003	CIKUPA	6	3206020006	CIKUPA	2
7	32.06.02.2004	KARANG-NUNGGAL	7	3206020007	KARANG-NUNGGAL	1
8	32.06.02.2005	KARANG MEKAR	8	3206020008	KARANG MEKAR	1
9	32.06.02.2007	CIBATUIRENG	9	3206020009	CIBATUIRENG	2
10	32.06.02.2008	CIBATU	10	3206020010	CIBATU	2
11	32.06.02.2010	SUKAWANGUN	11	3206020011	SUKAWANGUN	2
12	32.06.02.2011	CINTAWANGI	12	3206020012	CINTAWANGI	2
13	32.06.02.2006	CIKUKULU	13	3206020013	CIKUKULU	2
14	32.06.02.2009	SARIMANGGU	14	3206020014	SARIMANGGU	2

Catatan :
*) 1. Perkotaan
2. Perdesaan

https://jabar.bps.go.id

PROVINSI : [32] JAWA BARAT
KAB/KOTA : [06] TASIKMALAYA
KECAMATAN : [030] CIKALONG

Data Kemendagri			MFD 2021 Semester 2			
No	Kode	Nama Desa	No	Kode	Nama Desa	Status*
1	32.06.03.2008	MANDALA-JAYA	1	3206030001	MANDALA-JAYA	2
2	32.06.03.2001	CIKALONG	2	3206030002	CIKALONG	2
3	32.06.03.2003	CIKANCRA	3	3206030003	CIKANCRA	2
4	32.06.03.2013	TONJONGSARI	4	3206030004	TONJONGSARI	2
5	32.06.03.2004	SINGKIR	5	3206030005	SINGKIR	2
6	32.06.03.2005	PANYIARAN	6	3206030006	PANYIARAN	2
7	32.06.03.2006	CIBEBER	7	3206030007	CIBEBER	2
8	32.06.03.2009	CIDADALI	8	3206030008	CIDADALI	2
9	32.06.03.2012	KUBANGSARI	9	3206030009	KUBANGSARI	2
10	32.06.03.2007	CIKADU	10	3206030010	CIKADU	2
11	32.06.03.2011	SINDANGJAYA	11	3206030011	SINDANGJAYA	2
12	32.06.03.2002	KALAPAGENEP	12	3206030012	KALAPAGENEP	2
13	32.06.03.2010	CIMANUK	13	3206030013	CIMANUK	2

Catatan :
*) 1. Perkotaan
2. Perdesaan

https://jabar.bps.go.id

DAFTAR DESA/KELURAHAN

PROVINSI : [32] JAWA BARAT
KAB/KOTA : [06] TASIKMALAYA
KECAMATAN : [040] PANCATENGAH

Data Kemendagri			MFD 2021 Semester 2			
No	Kode	Nama Desa	No	Kode	Nama Desa	Status*
1	32.06.04.2009	MARGALUYU	1	3206040001	MARGALUYU	2
2	32.06.04.2001	CIBUNIASIH	2	3206040002	CIBUNIASIH	2
3	32.06.04.2002	PANGLIARAN	3	3206040003	PANGLIARAN	2
4	32.06.04.2011	PANCAWANGI	4	3206040004	PANCAWANGI	2
5	32.06.04.2008	JAYAMUKTI	5	3206040005	JAYAMUKTI	2
6	32.06.04.2003	TONJONG	6	3206040006	TONJONG	2
7	32.06.04.2004	CIBONGAS	7	3206040007	CIBONGAS	2
8	32.06.04.2007	CIKAWUNG	8	3206040008	CIKAWUNG	2
9	32.06.04.2005	TAWANG	9	3206040009	TAWANG	2
10	32.06.04.2010	MEKARSARI	10	3206040010	MEKARSARI	2
11	32.06.04.2006	NEGLASARI	11	3206040011	NEGLASARI	2

Catatan :
*) 1. Perkotaan
2. Perdesaan

https://jabar.bps.go.id

PROVINSI : [32] JAWA BARAT
KAB/KOTA : [06] TASIKMALAYA
KECAMATAN : [050] CIKATOMAS

Data Kemendagri			MFD 2021 Semester 2			
No	Kode	Nama Desa	No	Kode	Nama Desa	Status*
1	32.06.05.2001	GUNUNGSARI	1	3206050001	GUNUNGSARI	2
2	32.06.05.2002	CILUMBA	2	3206050002	CILUMBA	2
3	32.06.05.2009	LINGGALAK-SANA	3	3206050003	LINGGALAK-SANA	2
4	32.06.05.2003	PAKEMITAN	4	3206050004	PAKEMITAN	1
5	32.06.05.2004	COGREG	5	3206050005	COGREG	2
6	32.06.05.2006	LENGKONG BARANG	6	3206050006	LENGKONG BARANG	2
7	32.06.05.2008	TANJUNG BARANG	7	3206050007	TANJUNG BARANG	2
8	32.06.05.2005	CAYUR	8	3206050008	CAYUR	2
9	32.06.05.2007	SINDANG-KASIH	9	3206050009	SINDANG-KASIH	2

https://jabar.bps.go.id

Catatan :
*) 1. Perkotaan
2. Perdesaan

DAFTAR DESA/KELURAHAN

PROVINSI : [32] JAWA BARAT
KAB/KOTA : [06] TASIKMALAYA
KECAMATAN : [060] CIBALONG

Data Kemendagri			MFD 2021 Semester 2			
No	Kode	Nama Desa	No	Kode	Nama Desa	Status*
1	32.06.06.2003	EUREUNPALAY	1	3206060001	EUREUNPALAY	2
2	32.06.06.2002	SETIAWARAS	2	3206060002	SETIAWARAS	2
3	32.06.06.2001	CISEMPUR	3	3206060003	CISEMPUR	2
4	32.06.06.2006	PARUNG	4	3206060004	PARUNG	2
5	32.06.06.2004	CIBALONG	5	3206060005	CIBALONG	1
6	32.06.06.2005	SINGAJAYA	6	3206060006	SINGAJAYA	1

Catatan :
*) 1. Perkotaan
2. Perdesaan

https://jabar.bps.go.id

PROVINSI : [32] JAWA BARAT
KAB/KOTA : [06] TASIKMALAYA
KECAMATAN : [061] PARUNGPONTENG

Data Kemendagri			MFD 2021 Semester 2			
No	Kode	Nama Desa	No	Kode	Nama Desa	Status*
1	32.06.07.2008	KARYABAKTI	1	3206061001	KARYABAKTI	2
2	32.06.07.2002	CIGUNUNG	2	3206061002	CIGUNUNG	2
3	32.06.07.2005	CIBUNGUR	3	3206061003	CIBUNGUR	2
4	32.06.07.2001	PARUNGPON-TENG	4	3206061004	PARUNGPON-TENG	2
5	32.06.07.2007	GIRIKENCANA	5	3206061005	GIRIKENCANA	2
6	32.06.07.2004	BARUMEKAR	6	3206061006	BARUMEKAR	2
7	32.06.07.2003	CIBANTENG	7	3206061007	CIBANTENG	2
8	32.06.07.2006	BURUJULJAYA	8	3206061008	BURUJULJAYA	2

Catatan :
*) 1. Perkotaan
2. Perdesaan

https://jabar.bps.go.id

DAFTAR DESA/KELURAHAN

PROVINSI : [32] JAWA BARAT
KAB/KOTA : [06] TASIKMALAYA
KECAMATAN : [070] BANTARKALONG

Data Kemendagri			MFD 2021 Semester 2			
No	Kode	Nama Desa	No	Kode	Nama Desa	Status*
1	32.06.08.2008	SIRNAGALIH	1	3206070002	SIRNAGALIH	2
2	32.06.08.2001	SIMPANG	2	3206070003	SIMPANG	1
3	32.06.08.2006	HEGARWANGI	3	3206070004	HEGARWANGI	2
4	32.06.08.2005	WANGUNSARI	4	3206070005	WANGUNSARI	2
5	32.06.08.2003	PAMIJAHAN	5	3206070006	PAMIJAHAN	2
6	32.06.08.2002	PARAKAN-HONJE	6	3206070007	PARAKAN-HONJE	2
7	32.06.08.2004	SUKAMAJU	7	3206070008	SUKAMAJU	2
8	32.06.08.2007	WAKAP	8	3206070009	WAKAP	2

Catatan :
*) 1. Perkotaan
2. Perdesaan

https://jabar.bps.go.id

PROVINSI : [32] JAWA BARAT
KAB/KOTA : [06] TASIKMALAYA
KECAMATAN : [071] BOJONGASIH

Data Kemendagri			MFD 2021 Semester 2			
No	Kode	Nama Desa	No	Kode	Nama Desa	Status*
1	32.06.09.2005	GIRIJAYA	1	3206071001	GIRIJAYA	2
2	32.06.09.2003	BOJONGASIH	2	3206071002	BOJONGASIH	2
3	32.06.09.2004	SINDANGSARI	3	3206071003	SINDANGSARI	2
4	32.06.09.2002	CIKADONG-DONG	4	3206071004	CIKADONG-DONG	2
5	32.06.09.2001	MERTAJAYA	5	3206071005	MERTAJAYA	2
6	32.06.09.2006	TOBLONGAN	6	3206071006	TOBLONGAN	2

Catatan :
*) 1. Perkotaan
2. Perdesaan

https://jabar.bps.go.id

DAFTAR DESA/KELURAHAN

PROVINSI : [32] JAWA BARAT
KAB/KOTA : [06] TASIKMALAYA
KECAMATAN : [072] CULAMEGA

Data Kemendagri			MFD 2021 Semester 2			
No	Kode	Nama Desa	No	Kode	Nama Desa	Status*
1	32.06.10.2004	BOJONGSARI	1	3206072001	BOJONGSARI	2
2	32.06.10.2002	CINTABODAS	2	3206072002	CINTABODAS	2
3	32.06.10.2001	CIKUYA	3	3206072003	CIKUYA	2
4	32.06.10.2003	CIPICUNG	4	3206072004	CIPICUNG	2
5	32.06.10.2005	MEKARLAK-SANA	5	3206072005	MEKARLAK-SANA	2

Catatan :
*) 1. Perkotaan
2. Perdesaan

https://jabar.bps.go.id

PROVINSI : [32] JAWA BARAT
KAB/KOTA : [06] TASIKMALAYA
KECAMATAN : [080] BOJONGGAMBIR

Data Kemendagri			MFD 2021 Semester 2			
No	Kode	Nama Desa	No	Kode	Nama Desa	Status*
1	32.06.11.2006	CAMPAKASARI	1	3206080001	CAMPAKASARI	2
2	32.06.11.2001	BOJONGKA-POL	2	3206080002	BOJONGKA-POL	2
3	32.06.11.2005	WANDASARI	3	3206080003	WANDASARI	2
4	32.06.11.2002	PEDANGKA MULYAN	4	3206080004	PEDANGKA MULYAN	2
5	32.06.11.2008	KERTANEGLA	5	3206080005	KERTANEGLA	2
6	32.06.11.2003	BOJONGGAM-BIR	6	3206080006	BOJONGGAM-BIR	1
7	32.06.11.2007	MANGKON-JAYA	7	3206080007	MANGKON-JAYA	1
8	32.06.11.2004	CIROYOM	8	3206080008	CIROYOM	2
9	32.06.11.2009	PURWARA-HARJA	9	3206080009	PURWARA-HARJA	2
10	32.06.11.2010	GIRIMUKTI	10	3206080010	GIRIMUKTI	2

https://jabar.bps.go.id

Catatan :
*) 1. Perkotaan
2. Perdesaan

DAFTAR DESA/KELURAHAN

PROVINSI : [32] JAWA BARAT
KAB/KOTA : [06] TASIKMALAYA
KECAMATAN : [090] SODONGHILIR

Data Kemendagri			MFD 2021 Semester 2			
No	Kode	Nama Desa	No	Kode	Nama Desa	Status*
1	32.06.12.2009	CUKANGJAYA-GUNA	1	3206090001	CUKANGJAYA-GUNA	2
2	32.06.12.2012	SUKABAKTI	2	3206090002	SUKABAKTI	2
3	32.06.12.2001	PARUMASAN	3	3206090003	PARUMASAN	2
4	32.06.12.2008	SEPATNUNG-GAL	4	3206090004	SEPATNUNG-GAL	2
5	32.06.12.2010	RAKSAJAYA	5	3206090005	RAKSAJAYA	2
6	32.06.12.2003	SODONGHILIR	6	3206090006	SODONGHILIR	2
7	32.06.12.2002	CUKANG-KAWUNG	7	3206090007	CUKANG-KAWUNG	2
8	32.06.12.2004	CIKALONG	8	3206090008	CIKALONG	2
9	32.06.12.2005	CIPAINGEUN	9	3206090009	CIPAINGEUN	2
10	32.06.12.2011	PAKALONGAN	10	3206090010	PAKALONGAN	2
11	32.06.12.2006	LEUWI DULANG	11	3206090011	LEUWI DULANG	2
12	32.06.12.2007	MUNCANG	12	3206090012	MUNCANG	2

Catatan :
*) 1. Perkotaan
2. Perdesaan

https://jabar.bps.go.id

PROVINSI : [32] JAWA BARAT
KAB/KOTA : [06] TASIKMALAYA
KECAMATAN : [100] TARAJU

Data Kemendagri			MFD 2021 Semester 2			
No	Kode	Nama Desa	No	Kode	Nama Desa	Status*
1	32.06.13.2006	BANYUASIH	1	3206100001	BANYUASIH	2
2	32.06.13.2001	TARAJU	2	3206100002	TARAJU	2
3	32.06.13.2007	RAKSASARI	3	3206100003	RAKSASARI	2
4	32.06.13.2005	SINGASARI	4	3206100004	SINGASARI	1
5	32.06.13.2002	CIKUBANG	5	3206100005	CIKUBANG	2
6	32.06.13.2003	DEUDEUL	6	3206100006	DEUDEUL	2
7	32.06.13.2008	KERTARA-HARJA	7	3206100007	KERTARA-HARJA	2
8	32.06.13.2004	PURWARA-HAYU	8	3206100008	PURWARA-HAYU	2
9	32.06.13.2009	PAGERALAM	9	3206100009	PAGERALAM	2

Catatan :
*) 1. Perkotaan
2. Perdesaan

https://jabar.bps.go.id

DAFTAR DESA/KELURAHAN

PROVINSI : [32] JAWA BARAT
KAB/KOTA : [06] TASIKMALAYA
KECAMATAN : [110] SALAWU

Data Kemendagri			MFD 2021 Semester 2			
No	Kode	Nama Desa	No	Kode	Nama Desa	Status*
1	32.06.14.2009	SUKARASA	1	3206110009	SUKARASA	2
2	32.06.14.2001	JAHIANG	2	3206110010	JAHIANG	2
3	32.06.14.2007	SUNDA-WENANG	3	3206110011	SUNDA-WENANG	2
4	32.06.14.2008	KAWUNGSARI	4	3206110012	KAWUNGSARI	2
5	32.06.14.2006	TENJOWA RINGIN	5	3206110013	TENJOWA RINGIN	2
6	32.06.14.2010	KUTAWA RINGIN	6	3206110014	KUTAWA RINGIN	2
7	32.06.14.2005	TANJUNGSARI	7	3206110015	TANJUNGSARI	2
8	32.06.14.2004	NEGLASARI	8	3206110016	NEGLASARI	1
9	32.06.14.2011	KARANGMUKTI	9	3206110017	KARANGMUKTI	2
10	32.06.14.2003	SALAWU	10	3206110018	SALAWU	1
11	32.06.14.2012	MARGALAK-SANA	11	3206110019	MARGALAK-SANA	1
12	32.06.14.2002	SERANG	12	3206110020	SERANG	2

Catatan :
*) 1. Perkotaan
2. Perdesaan

https://jabar.bps.go.id

PROVINSI : [32] JAWA BARAT
KAB/KOTA : [06] TASIKMALAYA
KECAMATAN : [111] PUSPAHIANG

Data Kemendagri			MFD 2021 Semester 2			
No	Kode	Nama Desa	No	Kode	Nama Desa	Status*
1	32.06.15.2001	MANDALASARI	1	3206111001	MANDALASARI	2
2	32.06.15.2002	SUKASARI	2	3206111002	SUKASARI	2
3	32.06.15.2003	PUSPASARI	3	3206111003	PUSPASARI	2
4	32.06.15.2004	PUSPAHIANG	4	3206111004	PUSPAHIANG	2
5	32.06.15.2006	PUSPARAHAYU	5	3206111005	PUSPARAHAYU	2
6	32.06.15.2005	LUYUBAKTI	6	3206111006	LUYUBAKTI	2
7	32.06.15.2007	CIMANGGU	7	3206111007	CIMANGGU	2
8	32.06.15.2008	PUSPAJAYA	8	3206111008	PUSPAJAYA	2

Catatan :
*) 1. Perkotaan
2. Perdesaan

https://jabar.bps.go.id

DAFTAR DESA/KELURAHAN

PROVINSI : [32] JAWA BARAT
KAB/KOTA : [06] TASIKMALAYA
KECAMATAN : [120] TANJUNGJAYA

Data Kemendagri			MFD 2021 Semester 2			
No	Kode	Nama Desa	No	Kode	Nama Desa	Status*
1	32.06.16.2001	CIKEUSAL	1	3206120001	CIKEUSAL	2
2	32.06.16.2003	SUKANAGARA	2	3206120002	SUKANAGARA	2
3	32.06.16.2007	SUKASENANG	3	3206120003	SUKASENANG	2
4	32.06.16.2004	TANJUNGJAYA	4	3206120004	TANJUNGJAYA	2
5	32.06.16.2006	CINTAJAYA	5	3206120005	CINTAJAYA	2
6	32.06.16.2002	CIBALANARIK	6	3206120006	CIBALANARIK	1
7	32.06.16.2005	CILOLOHAN	7	3206120007	CILOLOHAN	2

Catatan :
*) 1. Perkotaan
2. Perdesaan

https://jabar.bps.go.id

PROVINSI : [32] JAWA BARAT
KAB/KOTA : [06] TASIKMALAYA
KECAMATAN : [130] SUKARAJA

Data Kemendagri			MFD 2021 Semester 2			
No	Kode	Nama Desa	No	Kode	Nama Desa	Status*
1	32.06.17.2004	MEKARJAYA	1	3206130001	MEKARJAYA	2
2	32.06.17.2003	SIRNAJAYA	2	3206130002	SIRNAJAYA	2
3	32.06.17.2006	JANGGALA	3	3206130003	JANGGALA	1
4	32.06.17.2001	SUKAPURA	4	3206130004	SUKAPURA	1
5	32.06.17.2008	TARUNAJAYA	5	3206130005	TARUNAJAYA	2
6	32.06.17.2002	LEUWIBUDAH	6	3206130006	LEUWIBUDAH	2
7	32.06.17.2005	LINGGARAJA	7	3206130007	LINGGARAJA	2
8	32.06.17.2007	MARGALAK-SANA	8	3206130008	MARGALAK-SANA	2

Catatan :
*) 1. Perkotaan
2. Perdesaan

https://jabar.bps.go.id

DAFTAR DESA/KELURAHAN

PROVINSI : [32] JAWA BARAT
KAB/KOTA : [06] TASIKMALAYA
KECAMATAN : [140] SALOPA

Data Kemendagri			MFD 2021 Semester 2			
No	Kode	Nama Desa	No	Kode	Nama Desa	Status*
1	32.06.18.2001	MANDALA-HAYU	1	3206140003	MANDALA-HAYU	2
2	32.06.18.2002	KARYAMAN-DALA	2	3206140004	KARYAMAN-DALA	2
3	32.06.18.2003	MULYASARI	3	3206140005	MULYASARI	2
4	32.06.18.2004	TANJUNGSARI	4	3206140006	TANJUNGSARI	2
5	32.06.18.2005	MANDALAGU-NA	5	3206140007	MANDALAGU-NA	2
6	32.06.18.2006	KAWITAN	6	3206140008	KAWITAN	2
7	32.06.18.2007	MANDALA-WANGI	7	3206140009	MANDALA-WANGI	2
8	32.06.18.2008	BANJARWA RINGIN	8	3206140010	BANJARWA RINGIN	2
9	32.06.18.2009	KARYAWANGI	9	3206140018	KARYAWANGI	2

Catatan :
*) 1. Perkotaan
2. Perdesaan

https://jabar.bps.go.id

PROVINSI : [32] JAWA BARAT
KAB/KOTA : [06] TASIKMALAYA
KECAMATAN : [141] JATIWARAS

Data Kemendagri			MFD 2021 Semester 2			
No	Kode	Nama Desa	No	Kode	Nama Desa	Status*
1	32.06.19.2009	MANDALA MEKAR	1	3206141001	MANDALA MEKAR	2
2	32.06.19.2008	KERSAGALIH	2	3206141002	KERSAGALIH	2
3	32.06.19.2007	CIWARAK	3	3206141003	CIWARAK	2
4	32.06.19.2005	JATIWARAS	4	3206141004	JATIWARAS	2
5	32.06.19.2006	PAPAYAN	5	3206141005	PAPAYAN	1
6	32.06.19.2004	NEGLASARI	6	3206141006	NEGLASARI	2
7	32.06.19.2001	KAPUTIHAN	7	3206141007	KAPUTIHAN	2
8	32.06.19.2002	SETIAWANGI	8	3206141008	SETIAWANGI	2
9	32.06.19.2003	SUKAKERTA	9	3206141009	SUKAKERTA	2
10	32.06.19.2010	KERTARAHAYU	10	3206141010	KERTARAHAYU	2
11	32.06.19.2011	MANDALA HURIP	11	3206141011	MANDALA HURIP	2

Catatan :
*) 1. Perkotaan
2. Perdesaan

https://jabar.bps.go.id

DAFTAR DESA/KELURAHAN

PROVINSI : [32] JAWA BARAT
KAB/KOTA : [06] TASIKMALAYA
KECAMATAN : [150] CINEAM

Data Kemendagri			MFD 2021 Semester 2			
No	Kode	Nama Desa	No	Kode	Nama Desa	Status*
1	32.06.20.2001	CISARUA	1	3206150001	CISARUA	2
2	32.06.20.2009	PASIRMUKTI	2	3206150006	PASIRMUKTI	2
3	32.06.20.2002	CIKONDANG	3	3206150007	CIKONDANG	2
4	32.06.20.2003	CIJULANG	4	3206150008	CIJULANG	2
5	32.06.20.2008	NAGARA TENGAH	5	3206150009	NAGARA TENGAH	2
6	32.06.20.2004	CIAMPANAN	6	3206150010	CIAMPANAN	2
7	32.06.20.2005	CINEAM	7	3206150011	CINEAM	1
8	32.06.20.2010	MADIASARI	8	3206150012	MADIASARI	2
9	32.06.20.2006	RAJADATU	9	3206150013	RAJADATU	2
10	32.06.20.2007	ANCOL	10	3206150014	ANCOL	2

Catatan :
*) 1. Perkotaan
2. Perdesaan

https://jabar.bps.go.id

PROVINSI : [32] JAWA BARAT
KAB/KOTA : [06] TASIKMALAYA
KECAMATAN : [151] KARANG JAYA

Data Kemendagri			MFD 2021 Semester 2			
No	Kode	Nama Desa	No	Kode	Nama Desa	Status*
1	32.06.21.2004	CITALAHAB	1	3206151001	CITALAHAB	2
2	32.06.21.2001	SIRNAJAYA	2	3206151002	SIRNAJAYA	2
3	32.06.21.2002	KARANG JAYA	3	3206151003	KARANG JAYA	2
4	32.06.21.2003	KARANG LAYUNG	4	3206151004	KARANG LAYUNG	2

Catatan :
*) 1. Perkotaan
2. Perdesaan

https://jabar.bps.go.id

DAFTAR DESA/KELURAHAN

PROVINSI : [32] JAWA BARAT
KAB/KOTA : [06] TASIKMALAYA
KECAMATAN : [160] MANONJAYA

Data Kemendagri			MFD 2021 Semester 2			
No	Kode	Nama Desa	No	Kode	Nama Desa	Status*
1	32.06.22.2011	BATUSUMUR	1	3206160007	BATUSUMUR	2
2	32.06.22.2001	CIHAUR	2	3206160008	CIHAUR	2
3	32.06.22.2003	PASIRPANJANG	3	3206160009	PASIRPANJANG	1
4	32.06.22.2009	KALIMANGGIS	4	3206160010	KALIMANGGIS	1
5	32.06.22.2004	CIBEBER	5	3206160011	CIBEBER	2
6	32.06.22.2012	GUNAJAYA	6	3206160012	GUNAJAYA	2
7	32.06.22.2010	MARGAHAYU	7	3206160013	MARGAHAYU	1
8	32.06.22.2005	KAMULYAN	8	3206160014	KAMULYAN	1
9	32.06.22.2006	MANONJAYA	9	3206160015	MANONJAYA	1
10	32.06.22.2007	MARGALUYU	10	3206160016	MARGALUYU	1
11	32.06.22.2002	CILANGKAP	11	3206160017	CILANGKAP	2
12	32.06.22.2008	PASIRBATANG	12	3206160018	PASIRBATANG	2

https://jabar.bps.go.id

Catatan :
*) 1. Perkotaan
2. Perdesaan

PROVINSI : [32] JAWA BARAT
KAB/KOTA : [06] TASIKMALAYA
KECAMATAN : [161] GUNUNG TANJUNG

Data Kemendagri			MFD 2021 Semester 2			
No	Kode	Nama Desa	No	Kode	Nama Desa	Status*
1	32.06.23.2001	CINUNJANG	1	3206161001	CINUNJANG	2
2	32.06.23.2007	MALATISUKA	2	3206161002	MALATISUKA	2
3	32.06.23.2006	GIRIWANGI	3	3206161003	GIRIWANGI	2
4	32.06.23.2004	JATIJAYA	4	3206161004	JATIJAYA	2
5	32.06.23.2002	GUNUNG TANJUNG	5	3206161005	GUNUNG TANJUNG	2
6	32.06.23.2005	TANJUNGSARI	6	3206161006	TANJUNGSARI	1
7	32.06.23.2003	BOJONGSARI	7	3206161007	BOJONGSARI	2

Catatan :
*) 1. Perkotaan
2. Perdesaan

https://jabar.bps.go.id

DAFTAR DESA/KELURAHAN

PROVINSI : [32] JAWA BARAT
KAB/KOTA : [06] TASIKMALAYA
KECAMATAN : [190] SINGAPARNA

Data Kemendagri			MFD 2021 Semester 2			
No	Kode	Nama Desa	No	Kode	Nama Desa	Status*
1	32.06.24.2007	SUKAASIH	1	3206190007	SUKAASIH	1
2	32.06.24.2001	CIKUTEN	2	3206190008	CIKUTEN	1
3	32.06.24.2010	SUKAHERANG	3	3206190009	SUKAHERANG	1
4	32.06.24.2009	SINGASARI	4	3206190010	SINGASARI	1
5	32.06.24.2002	SINGAPARNA	5	3206190011	SINGAPARNA	1
6	32.06.24.2008	SUKAMULYA	6	3206190012	SUKAMULYA	1
7	32.06.24.2003	CIPAKAT	7	3206190013	CIPAKAT	1
8	32.06.24.2004	CINTARAJA	8	3206190020	CINTARAJA	1
9	32.06.24.2005	CIKUNIR	9	3206190021	CIKUNIR	1
10	32.06.24.2006	CIKADONG-DONG	10	3206190022	CIKADONG-DONG	1

Catatan :
*) 1. Perkotaan
2. Perdesaan

https://jabar.bps.go.id

PROVINSI : [32] JAWA BARAT
KAB/KOTA : [06] TASIKMALAYA
KECAMATAN : [191] SUKARAME

Data Kemendagri			MFD 2021 Semester 2			
No	Kode	Nama Desa	No	Kode	Nama Desa	Status*
1	32.06.26.2005	SUKARAPIH	1	3206191001	SUKARAPIH	1
2	32.06.26.2006	WARGAKERTA	2	3206191002	WARGAKERTA	2
3	32.06.26.2002	SUKAMENAK	3	3206191003	SUKAMENAK	1
4	32.06.26.2004	PADASUKA	4	3206191004	PADASUKA	2
5	32.06.26.2003	SUKARASA	5	3206191005	SUKARASA	1
6	32.06.26.2001	SUKARAME	6	3206191006	SUKARAME	1

Catatan :
*) 1. Perkotaan
2. Perdesaan

https://jabar.bps.go.id

DAFTAR DESA/KELURAHAN

PROVINSI : [32] JAWA BARAT
KAB/KOTA : [06] TASIKMALAYA
KECAMATAN : [192] MANGUNREJA

Data Kemendagri			MFD 2021 Semester 2			
No	Kode	Nama Desa	No	Kode	Nama Desa	Status*
1	32.06.25.2005	PASIRSALAM	1	3206192001	PASIRSALAM	2
2	32.06.25.2006	SUKALUYU	2	3206192002	SUKALUYU	2
3	32.06.25.2001	SUKASUKUR	3	3206192003	SUKASUKUR	2
4	32.06.25.2002	SALEBU	4	3206192004	SALEBU	2
5	32.06.25.2003	MANGUNREJA	5	3206192005	MANGUNREJA	1
6	32.06.25.2004	MARGAJAYA	6	3206192006	MARGAJAYA	2

Catatan :
*) 1. Perkotaan
2. Perdesaan

https://jabar.bps.go.id

PROVINSI : [32] JAWA BARAT
KAB/KOTA : [06] TASIKMALAYA
KECAMATAN : [200] CIGALONTANG

Data Kemendagri			MFD 2021 Semester 2			
No	Kode	Nama Desa	No	Kode	Nama Desa	Status*
1	32.06.27.2014	SIRNAGALIH	1	3206200001	SIRNAGALIH	2
2	32.06.27.2001	KERSAMAJU	2	3206200002	KERSAMAJU	2
3	32.06.27.2015	TANJUNGKA-RANG	3	3206200003	TANJUNGKA-RANG	2
4	32.06.27.2002	NANGTANG	4	3206200004	NANGTANG	2
5	32.06.27.2003	PUSPARAJA	5	3206200005	PUSPARAJA	2
6	32.06.27.2004	JAYAPURA	6	3206200006	JAYAPURA	2
7	32.06.27.2005	LENGKONG-JAYA	7	3206200007	LENGKONG-JAYA	2
8	32.06.27.2012	TENJONAGARA	8	3206200008	TENJONAGARA	2
9	32.06.27.2006	NANGGERANG	9	3206200009	NANGGERANG	1
10	32.06.27.2007	SUKAMANAH	10	3206200010	SUKAMANAH	1
11	32.06.27.2016	SIRNAPUTRA	11	3206200011	SIRNAPUTRA	2
12	32.06.27.2008	SIRNARAJA	12	3206200012	SIRNARAJA	2
13	32.06.27.2013	CIGALONTANG	13	3206200013	CIGALONTANG	2
14	32.06.27.2011	PUSPAMUKTI	14	3206200014	PUSPAMUKTI	2
15	32.06.27.2009	CIDUGALEUN	15	3206200015	CIDUGALEUN	2
16	32.06.27.2010	PARENTAS	16	3206200016	PARENTAS	2

Catatan :
*) 1. Perkotaan
2. Perdesaan

https://jabar.bps.go.id

DAFTAR DESA/KELURAHAN

PROVINSI : [32] JAWA BARAT
KAB/KOTA : [06] TASIKMALAYA
KECAMATAN : [210] LEUWISARI

Data Kemendagri			MFD 2021 Semester 2			
No	Kode	Nama Desa	No	Kode	Nama Desa	Status*
1	32.06.28.2001	ARJASARI	1	3206210003	ARJASARI	1
2	32.06.28.2002	CIAWANG	2	3206210007	CIAWANG	2
3	32.06.28.2005	JAYAMUKTI	3	3206210008	JAYAMUKTI	1
4	32.06.28.2004	LINGGAWANGI	4	3206210015	LINGGAWANGI	2
5	32.06.28.2007	LINGGAMULYA	5	3206210016	LINGGAMULYA	2
6	32.06.28.2003	CIGADOG	6	3206210017	CIGADOG	2
7	32.06.28.2006	MANDALAGIRI	7	3206210018	MANDALAGIRI	2

Catatan :
*) 1. Perkotaan
2. Perdesaan

https://jabar.bps.go.id

PROVINSI : [32] JAWA BARAT
KAB/KOTA : [06] TASIKMALAYA
KECAMATAN : [211] SARIWANGI

Data Kemendagri			MFD 2021 Semester 2			
No	Kode	Nama Desa	No	Kode	Nama Desa	Status*
1	32.06.30.2005	SIRNASARI	1	3206211001	SIRNASARI	1
2	32.06.30.2004	LINGGASIRNA	2	3206211002	LINGGASIRNA	2
3	32.06.30.2007	SELAWANGI	3	3206211003	SELAWANGI	1
4	32.06.30.2001	SARIWANGI	4	3206211004	SARIWANGI	1
5	32.06.30.2008	JAYAPUTRA	5	3206211005	JAYAPUTRA	1
6	32.06.30.2003	JAYARATU	6	3206211006	JAYARATU	1
7	32.06.30.2006	SUKAMULIH	7	3206211007	SUKAMULIH	1
8	32.06.30.2002	SUKAHARJA	8	3206211008	SUKAHARJA	1

Catatan :
*) 1. Perkotaan
2. Perdesaan

https://jabar.bps.go.id

DAFTAR DESA/KELURAHAN

PROVINSI : [32] JAWA BARAT
KAB/KOTA : [06] TASIKMALAYA
KECAMATAN : [212] PADAKEMBANG

Data Kemendagri			MFD 2021 Semester 2			
No	Kode	Nama Desa	No	Kode	Nama Desa	Status*
1	32.06.29.2001	CILAMPUNG-HILIR	1	3206212001	CILAMPUNG-HILIR	1
2	32.06.29.2002	RANCAPAKU	2	3206212002	RANCAPAKU	2
3	32.06.29.2004	MEKARJAYA	3	3206212003	CISARUNI	1
4	32.06.29.2005	PADAKEM-BANG	4	3206212004	PADAKEM-BANG	2
5	32.06.29.2003	MEKARJAYA	5	3206212005	MEKARJAYA	2

Catatan :
*) 1. Perkotaan
2. Perdesaan

https://jabar.bps.go.id

PROVINSI : [32] JAWA BARAT
KAB/KOTA : [06] TASIKMALAYA
KECAMATAN : [221] SUKARATU

Data Kemendagri			MFD 2021 Semester 2			
No	Kode	Nama Desa	No	Kode	Nama Desa	Status*
1	32.06.31.2002	TAWANGBAN-TENG	1	3206221001	TAWANGBAN-TENG	2
2	32.06.31.2004	GUNUNGSARI	2	3206221002	GUNUNGSARI	2
3	32.06.31.2005	SUKAMAHI	3	3206221003	SUKAMAHI	2
4	32.06.31.2006	SUKAGALIH	4	3206221004	SUKAGALIH	2
5	32.06.31.2008	INDRAJAYA	5	3206221005	INDRAJAYA	2
6	32.06.31.2007	SUKARATU	6	3206221006	SUKARATU	2
7	32.06.31.2003	SINAGAR	7	3206221007	SINAGAR	2
8	32.06.31.2001	LINGGAJATI	8	3206221008	LINGGAJATI	2

Catatan :
*) 1. Perkotaan
2. Perdesaan

https://jabar.bps.go.id

DAFTAR DESA/KELURAHAN

PROVINSI : [32] JAWA BARAT
KAB/KOTA : [06] TASIKMALAYA
KECAMATAN : [230] CISAYONG

Data Kemendagri			MFD 2021 Semester 2			
No	Kode	Nama Desa	No	Kode	Nama Desa	Status*
1	32.06.32.2013	SANTANAME-KAR	1	3206230001	SANTANAME-KAR	2
2	32.06.32.2001	CISAYONG	2	3206230002	CISAYONG	1
3	32.06.32.2002	SUKAJADI	3	3206230003	SUKAJADI	2
4	32.06.32.2003	SUKASUKUR	4	3206230004	SUKASUKUR	2
5	32.06.32.2008	JATIHURIP	5	3206230005	JATIHURIP	1
6	32.06.32.2011	SUKARAHARJA	6	3206230006	SUKARAHARJA	2
7	32.06.32.2012	MEKARWANGI	7	3206230007	MEKARWANGI	2
8	32.06.32.2005	NUSAWANGI	8	3206230008	NUSAWANGI	2
9	32.06.32.2006	CIKADU	9	3206230009	CIKADU	1
10	32.06.32.2010	PURWASARI	10	3206230010	PURWASARI	2
11	32.06.32.2007	CILEULEUS	11	3206230011	CILEULEUS	2
12	32.06.32.2009	SUKASETIA	12	3206230013	SUKASETIA	2
13	32.06.32.2004	SUKAMUKTI	13	3206230014	SUKAMUKTI	2

Catatan :
*) 1. Perkotaan
2. Perdesaan

https://jabar.bps.go.id

PROVINSI : [32] JAWA BARAT
KAB/KOTA : [06] TASIKMALAYA
KECAMATAN : [231] SUKAHENING

Data Kemendagri			MFD 2021 Semester 2			
No	Kode	Nama Desa	No	Kode	Nama Desa	Status*
1	32.06.33.2001	BANYURASA	1	3206231001	BANYURASA	2
2	32.06.33.2006	BANYURESMI	2	3206231002	BANYURESMI	2
3	32.06.33.2002	CALINCING	3	3206231003	CALINCING	2
4	32.06.33.2005	KUDADEPA	4	3206231004	KUDADEPA	2
5	32.06.33.2007	SUNDAKERTA	5	3206231005	SUNDAKERTA	2
6	32.06.33.2003	SUKAHENING	6	3206231006	SUKAHENING	2
7	32.06.33.2004	KIARA-JANGKUNG	7	3206231007	KIARA-JANGKUNG	2

Catatan :
*) 1. Perkotaan
2. Perdesaan

https://jabar.bps.go.id

DAFTAR DESA/KELURAHAN

PROVINSI : [32] JAWA BARAT
KAB/KOTA : [06] TASIKMALAYA
KECAMATAN : [240] RAJAPOLAH

Data Kemendagri			MFD 2021 Semester 2			
No	Kode	Nama Desa	No	Kode	Nama Desa	Status*
1	32.06.24.2006	RAJAMAN-DALA	1	3206240001	RAJAMAN-DALA	2
2	32.06.24.2001	DAWAGUNG	2	3206240002	DAWAGUNG	1
3	32.06.24.2002	RAJAPOLAH	3	3206240003	RAJAPOLAH	1
4	32.06.24.2003	MANGGUNG-JAYA	4	3206240004	MANGGUNG-JAYA	1
5	32.06.24.2007	SUKANAGALIH	5	3206240005	SUKANAGALIH	1
6	32.06.24.2005	SUKARAJA	6	3206240006	SUKARAJA	2
7	32.06.24.2004	MANGGUNG-SARI	7	3206240007	MANGGUNG-SARI	1
8	32.06.24.2008	TANJUNGPURA	8	3206240008	TANJUNGPURA	1

Catatan :
*) 1. Perkotaan
2. Perdesaan

https://jabar.bps.go.id

PROVINSI : [32] JAWA BARAT
KAB/KOTA : [06] TASIKMALAYA
KECAMATAN : [250] JAMANIS

Data Kemendagri			MFD 2021 Semester 2			
No	Kode	Nama Desa	No	Kode	Nama Desa	Status*
1	32.06.35.2006	KARANGSEM-BUNG	1	3206250001	KARANGSEM-BUNG	2
2	32.06.35.2001	CONDONG	2	3206250002	CONDONG	2
3	32.06.35.2002	BOJONGGAOK	3	3206250003	BOJONGGAOK	2
4	32.06.35.2003	SINDANGRAJA	4	3206250004	SINDANGRAJA	1
5	32.06.35.2007	TANJUNGME-KAR	5	3206250005	TANJUNGME-KAR	2
6	32.06.35.2004	KARANG MULYA	6	3206250006	KARANG MULYA	2
7	32.06.35.2008	KARANGRESIK	7	3206250007	KARANGRESIK	1
8	32.06.35.2005	GERESIK	8	3206250008	GERESIK	2

Catatan :
*) 1. Perkotaan
2. Perdesaan

https://jabar.bps.go.id

DAFTAR DESA/KELURAHAN

PROVINSI : [32] JAWA BARAT
KAB/KOTA : [06] TASIKMALAYA
KECAMATAN : [260] CIAWI

Data Kemendagri			MFD 2021 Semester 2			
No	Kode	Nama Desa	No	Kode	Nama Desa	Status*
1	32.06.36.2009	KERTAMUKTI	1	3206260001	KERTAMUKTI	2
2	32.06.36.2001	GOMBONG	2	3206260002	GOMBONG	2
3	32.06.36.2002	BUGEL	3	3206260003	BUGEL	2
4	32.06.36.2003	MARGASARI	4	3206260004	MARGASARI	1
5	32.06.36.2011	PAKEMITAN KIDUL	5	3206260005	PAKEMITAN KIDUL	1
6	32.06.36.2005	CIAWI	6	3206260006	CIAWI	1
7	32.06.36.2008	CITAMBA	7	3206260007	CITAMBA	2
8	32.06.36.2010	KURNIABAKTI	8	3206260008	KURNIABAKTI	1
9	32.06.36.2004	PAKEMITAN	9	3206260009	PAKEMITAN	1
10	32.06.36.2006	SUKAMANTRI	10	3206260010	SUKAMANTRI	1
11	32.06.36.2007	PASIRHUNI	11	3206260011	PASIRHUNI	1

Catatan :
*) 1. Perkotaan
2. Perdesaan

https://jabar.bps.go.id

PROVINSI : [32] JAWA BARAT
KAB/KOTA : [06] TASIKMALAYA
KECAMATAN : [261] KADIPATEN

Data Kemendagri			MFD 2021 Semester 2			
No	Kode	Nama Desa	No	Kode	Nama Desa	Status*
1	32.06.37.2006	PAMOYANAN	1	3206261001	PAMOYANAN	1
2	32.06.37.2005	BUNIASIH	2	3206261002	BUNIASIH	2
3	32.06.37.2004	MEKARSARI	3	3206261003	MEKARSARI	2
4	32.06.37.2002	DIRGAHAYU	4	3206261004	DIRGAHAYU	2
5	32.06.37.2003	CIBAHAYU	5	3206261005	CIBAHAYU	2
6	32.06.37.2001	KADIPATEN	6	3206261006	KADIPATEN	2

Catatan :
*) 1. Perkotaan
2. Perdesaan

https://jabar.bps.go.id

DAFTAR DESA/KELURAHAN

PROVINSI : [32] JAWA BARAT
KAB/KOTA : [06] TASIKMALAYA
KECAMATAN : [270] PAGERAGEUNG

Data Kemendagri			MFD 2021 Semester 2			
No	Kode	Nama Desa	No	Kode	Nama Desa	Status*
1	32.06.38.2001	CIPACING	1	3206270007	CIPACING	2
2	32.06.38.2002	SUKAMAJU	2	3206270010	SUKAMAJU	2
3	32.06.38.2003	PAGERSARI	3	3206270011	PAGERSARI	2
4	32.06.38.2004	PAGER-AGEUNG	4	3206270012	PAGER-AGEUNG	1
5	32.06.38.2005	SUKADANA	5	3206270013	SUKADANA	2
6	32.06.38.2006	PUTERAN	6	3206270014	PUTERAN	1
7	32.06.38.2007	TANJUNG KERTA	7	3206270015	TANJUNG KERTA	1
8	32.06.38.2008	GURANTENG	8	3206270016	GURANTENG	2
9	32.06.38.2009	NANGGEWER	9	3206270017	NANGGEWER	2
10	32.06.38.2010	SUKAPADA	10	3206270018	SUKAPADA	2

Catatan :
*) 1. Perkotaan
2. Perdesaan

https://jabar.bps.go.id

PROVINSI : [32] JAWA BARAT
KAB/KOTA : [06] TASIKMALAYA
KECAMATAN : [271] SUKARESIK

Data Kemendagri			MFD 2021 Semester 2			
No	Kode	Nama Desa	No	Kode	Nama Desa	Status*
1	32.06.39.2008	MARGAMULYA	1	3206271001	MARGAMULYA	2
2	32.06.39.2001	CIPONDOK	2	3206271002	CIPONDOK	1
3	32.06.39.2002	SUKAMENAK	3	3206271003	SUKAMENAK	2
4	32.06.39.2007	SUKARESIK	4	3206271004	SUKARESIK	2
5	32.06.39.2003	SUKARATU	5	3206271005	SUKARATU	1
6	32.06.39.2004	BANJARSARI	6	3206271006	BANJARSARI	2
7	32.06.39.2006	SUKAPANCAR	7	3206271007	SUKAPANCAR	2
8	32.06.39.2005	TANJUNGSARI	8	3206271008	TANJUNGSARI	2

Catatan :
*) 1. Perkotaan
2. Perdesaan

https://jabar.bps.go.id

https://jabar.bps.go.id

KABUPATEN CIAMIS

https://jabar.bps.go.id

https://jabar.bps.go.id

PROVINSI : [32] JAWA BARAT
KAB/KOTA : [07] CIAMIS

Data Kemendagri			MFD 2021 Semester 2		
No	Kode	Nama Kecamatan	No	Kode	Nama Kecamatan
1	32.07.18	BANJARSARI	1	3207100	BANJARSARI
2	32.07.37	BANJARANYAR	2	3207101	BANJARANYAR
3	32.07.17	LAKBOK	3	3207110	LAKBOK
4	32.07.35	PURWADADI	4	3207111	PURWADADI
5	32.07.19	PAMARICAN	5	3207120	PAMARICAN
6	32.07.05	CIDOLOG	6	3207130	CIDOLOG
7	32.07.29	CIMARAGAS	7	3207140	CIMARAGAS
8	32.07.03	CIJEUNGJING	8	3207150	CIJEUNGJING
9	32.07.30	CISAGA	9	3207160	CISAGA
10	32.07.16	TAMBAKSARI	10	3207170	TAMBAKSARI
11	32.07.15	RANCAH	11	3207180	RANCAH
12	32.07.13	RAJADESA	12	3207190	RAJADESA
13	32.07.14	SUKADANA	13	3207200	SUKADANA
14	32.07.01	CIAMIS	14	3207210	CIAMIS
15	32.07.32	BAREGBEG	15	3207211	BAREGBEG
16	32.07.02	CIKONENG	16	3207220	CIKONENG
17	32.07.31	SINDANGKASIH	17	3207221	SINDANGKASIH
18	32.07.06	CIHAURBEUTI	18	3207230	CIHAURBEUTI
19	32.07.04	SADANANYA	19	3207240	SADANANYA
20	32.07.11	CIPAKU	20	3207250	CIPAKU
21	32.07.12	JATINAGARA	21	3207260	JATINAGARA
22	32.07.10	PANAWANGAN	22	3207270	PANAWANGAN
23	32.07.09	KAWALI	23	3207280	KAWALI
24	32.07.34	LUMBUNG	24	3207281	LUMBUNG
25	32.07.08	PANJALU	25	3207290	PANJALU
26	32.07.33	SUKAMANTRI	26	3207291	SUKAMANTRI
27	32.07.07	PANUMBANGAN	27	3207300	PANUMBANGAN

https://jabar.bps.go.id

JUMLAH DESA/KELURAHAN PER KECAMATAN

PROVINSI : [32] JAWA BARAT
KAB/KOTA : [07] CIAMIS

Data Kemendagri				MFD 2021 Semester 2			
No	Kode	Nama Kecamatan	Jml Desa	No	Kode	Nama Kecamatan	Jml Desa
1	32.07.18	BANJARSARI	12	1	3207100	BANJARSARI	12
2	32.07.37	BANJARANYAR	10	2	3207101	BANJARANYAR	10
3	32.07.17	LAKBOK	10	3	3207110	LAKBOK	10
4	32.07.35	PURWADADI	9	4	3207111	PURWADADI	9
5	32.07.19	PAMARICAN	14	5	3207120	PAMARICAN	14
6	32.07.05	CIDOLOG	6	6	3207130	CIDOLOG	6
7	32.07.29	CIMARAGAS	5	7	3207140	CIMARAGAS	5
8	32.07.03	CIJEUNGJING	11	8	3207150	CIJEUNGJING	11
9	32.07.30	CISAGA	11	9	3207160	CISAGA	11
10	32.07.16	TAMBAKSARI	6	10	3207170	TAMBAKSARI	6
11	32.07.15	RANCAH	13	11	3207180	RANCAH	13
12	32.07.13	RAJADESA	11	12	3207190	RAJADESA	11
13	32.07.14	SUKADANA	6	13	3207200	SUKADANA	6
14	32.07.01	CIAMIS	12	14	3207210	CIAMIS	12
15	32.07.32	BAREGBEG	9	15	3207211	BAREGBEG	9
16	32.07.02	CIKONENG	9	16	3207220	CIKONENG	9
17	32.07.31	SINDANGKASIH	9	17	3207221	SINDANGKASIH	9
18	32.07.06	CIHAURBEUTI	11	18	3207230	CIHAURBEUTI	11
19	32.07.04	SADANANYA	8	19	3207240	SADANANYA	8
20	32.07.11	CIPAKU	13	20	3207250	CIPAKU	13
21	32.07.12	JATINAGARA	6	21	3207260	JATINAGARA	6
22	32.07.10	PANAWANGAN	18	22	3207270	PANAWANGAN	18
23	32.07.09	KAWALI	11	23	3207280	KAWALI	11
24	32.07.34	LUMBUNG	8	24	3207281	LUMBUNG	8
25	32.07.08	PANJALU	8	25	3207290	PANJALU	8
26	32.07.33	SUKAMANTRI	5	26	3207291	SUKAMANTRI	5
27	32.07.07	PANUMBANGAN	14	27	3207300	PANUMBANGAN	14

https://jabar.bps.go.id

PROVINSI : [32] JAWA BARAT
KAB/KOTA : [07] CIAMIS
KECAMATAN : [10] BANJARSARI

Data Kemendagri			MFD 2021 Semester 2			
No	Kode	Nama Desa	No	Kode	Nama Desa	Status*
1	32.07.18.2018	SUKASARI	1	3207100009	SUKASARI	1
2	32.07.18.2005	KAWASEN	2	3207100011	KAWASEN	2
3	32.07.18.2007	CIBADAK	3	3207100012	CIBADAK	1
4	32.07.18.2008	BANJARSARI	4	3207100013	BANJARSARI	1
5	32.07.18.2012	SINDANGSARI	5	3207100014	SINDANGSARI	1
6	32.07.18.2009	SINDANGHAYU	6	3207100015	SINDANGHAYU	2
7	32.07.18.2010	SINDANGASIH	7	3207100016	SINDANGASIH	2
8	32.07.18.2014	PURWASARI	8	3207100017	PURWASARI	2
9	32.07.18.2013	CIHERANG	9	3207100018	CIHERANG	1
10	32.07.18.2015	RATAWANGI	10	3207100019	RATAWANGI	2
12	32.07.18.2006	CICAPAR	11	3207100020	CICAPAR	2
13	32.07.18.2016	CIULU	12	3207100021	CIULU	2

Catatan :
*) 1. Perkotaan
2. Perdesaan

https://jabar.bps.go.id

DAFTAR DESA/KELURAHAN

PROVINSI : [32] JAWA BARAT
KAB/KOTA : [07] CIAMIS
KECAMATAN : [101] BANJARANYAR

Data Kemendagri			MFD 2021 Semester 2			
No	Kode	Nama Desa	No	Kode	Nama Desa	Status*
1	32.07.18.2020	CIKUPA	1	3207101001	CIKUPA	2
2	32.07.18.2021	KARYAMUKTI	2	3207101002	KARYAMUKTI	2
3	32.07.18.2003	CIGAYAM	3	3207101003	CIGAYAM	2
4	32.07.18.2002	BANJARANYAR	4	3207101004	BANJARANYAR	2
5	32.07.18.2011	KALIJAYA	5	3207101005	KALIJAYA	2
6	32.07.18.2001	PASAWAHAN	6	3207101006	PASAWAHAN	2
7	32.07.18.2019	CIKASO	7	3207101007	CIKASO	2
8	32.07.18.2017	SINDANGRASA	8	3207101008	SINDANGRASA	2
9	32.07.18.2004	LANGKAPSARI	9	3207101009	LANGKAPSARI	2
10	32.07.18.2022	TANJUNGSARI	10	3207101010	TANJUNGSARI	2

https://jabar.bps.go.id

Catatan :
*) 1. Perkotaan
2. Perdesaan

PROVINSI : [32] JAWA BARAT
KAB/KOTA : [07] CIAMIS
KECAMATAN : [110] LAKBOK

Data Kemendagri			MFD 2021 Semester 2			
No	Kode	Nama Desa	No	Kode	Nama Desa	Status*
1	32.07.17.2006	SINDANG ANGIN	1	3207110001	SINDANG ANGIN	2
2	32.07.17.2007	PULOERANG	2	3207110002	PULOERANG	2
3	32.07.17.2009	KALAPASAWIT	3	3207110003	KALAPASAWIT	2
4	32.07.17.2010	SUKANAGARA	4	3207110004	SUKANAGARA	2
5	32.07.17.2011	KERTAJAYA	5	3207110005	KERTAJAYA	2
6	32.07.17.2012	SIDAHARJA	6	3207110006	SIDAHARJA	2
7	32.07.17.2013	BAREGBEG	7	3207110007	BAREGBEG	2
8	32.07.17.2017	CINTAJAYA	8	3207110008	CINTAJAYA	1
9	32.07.17.2018	TAMBAKREJA	9	3207110009	TAMBAKREJA	2
10	32.07.17.2019	CINTARATU	10	3207110010	CINTARATU	1

Catatan :
*) 1. Perkotaan
2. Perdesaan

https://jabar.bps.go.id

DAFTAR DESA/KELURAHAN

PROVINSI : [32] JAWA BARAT
KAB/KOTA : [07] CIAMIS
KECAMATAN : [111] PURWADADI

Data Kemendagri			MFD 2021 Semester 2			
No	Kode	Nama Desa	No	Kode	Nama Desa	Status*
1	32.07.26.2008	KUTAWA RINGIN	1	3207111001	KUTAWA RINGIN	2
2	32.07.26.2001	BANTARDAWA	2	3207111002	BANTARDAWA	2
3	32.07.26.2007	PASIRLAWANG	3	3207111003	PASIRLAWANG	2
4	32.07.26.2002	PURWADADI	4	3207111004	PURWADADI	2
5	32.07.26.2003	PURWAJAYA	5	3207111005	PURWAJAYA	2
6	32.07.26.2005	SIDARAHAYU	6	3207111006	SIDARAHAYU	2
7	32.07.26.2004	KARANGPA NINGAL	7	3207111007	KARANGPA NINGAL	2
8	32.07.26.2009	SUKAMULYA	8	3207111008	SUKAMULYA	2
9	32.07.26.2006	PADARINGAN	9	3207111009	PADARINGAN	2

Catatan :
*) 1. Perkotaan
2. Perdesaan

https://jabar.bps.go.id

PROVINSI : [32] JAWA BARAT
KAB/KOTA : [07] CIAMIS
KECAMATAN : [120] PAMARICAN

Data Kemendagri			MFD 2021 Semester 2			
No	Kode	Nama Desa	No	Kode	Nama Desa	Status*
1	32.07.19.2002	SIDAMULIH	1	3207120001	SIDAMULIH	2
2	32.07.19.2008	MARGAJAYA	2	3207120002	MARGAJAYA	2
3	32.07.19.2006	NEGLASARI	3	3207120003	NEGLASARI	2
4	32.07.19.2001	PAMARICAN	4	3207120004	PAMARICAN	2
5	32.07.19.2010	SUKAHURIP	5	3207120005	SUKAHURIP	2
6	32.07.19.2003	KERTAHAYU	6	3207120006	KERTAHAYU	2
7	32.07.19.2011	SUKAJADI	7	3207120007	SUKAJADI	1
8	32.07.19.2004	SUKAMUKTI	8	3207120008	SUKAMUKTI	2
9	32.07.19.2012	SIDAHARJA	9	3207120009	SIDAHARJA	2
10	32.07.19.2005	BANGUNSARI	10	3207120010	BANGUNSARI	2
11	32.07.19.2009	SUKAJAYA	11	3207120011	SUKAJAYA	2
12	32.07.19.2007	BANTARSARI	12	3207120012	BANTARSARI	2
13	32.07.19.2013	PASIRNAGARA	13	3207120013	PASIRNAGARA	2
14	32.07.19.2014	MEKARMULYA	14	3207120014	MEKARMULYA	2

Catatan :
*) 1. Perkotaan
2. Perdesaan

https://jabar.bps.go.id

DAFTAR DESA/KELURAHAN

PROVINSI : [32] JAWA BARAT
KAB/KOTA : [07] CIAMIS
KECAMATAN : [130] CIDOLOG

Data Kemendagri			MFD 2021 Semester 2			
No	Kode	Nama Desa	No	Kode	Nama Desa	Status*
1	32.07.05.2004	JELEGONG	1	3207130001	JELEGONG	2
2	32.07.05.2005	CIPARAY	2	3207130002	CIPARAY	2
3	32.07.05.2001	CIDOLOG	3	3207130003	CIDOLOG	2
4	32.07.05.2002	JANGGALA	4	3207130004	JANGGALA	2
5	32.07.05.2003	HEGARMANAH	5	3207130005	HEGARMANAH	2
6	32.07.05.2006	SUKASARI	6	3207130006	SUKASARI	2

Catatan :
*) 1. Perkotaan
2. Perdesaan

https://jabar.bps.go.id

PROVINSI : [32] JAWA BARAT
KAB/KOTA : [07] CIAMIS
KECAMATAN : [140] CIMARAGAS

Data Kemendagri			MFD 2021 Semester 2			
No	Kode	Nama Desa	No	Kode	Nama Desa	Status*
1	32.07.20.2004	BOJONG-MALANG	1	3207140001	BOJONG-MALANG	2
2	32.07.20.2003	RAKSABAYA	2	3207140002	RAKSABAYA	2
3	32.07.20.2002	BEBER	3	3207140003	BEBER	2
4	32.07.20.2001	CIMARAGAS	4	3207140004	CIMARAGAS	2
5	32.07.20.2005	JAYARAKSA	5	3207140005	JAYARAKSA	2

Catatan :
*) 1. Perkotaan
2. Perdesaan

https://jabar.bps.go.id

DAFTAR DESA/KELURAHAN

PROVINSI : [32] JAWA BARAT
KAB/KOTA : [07] CIAMIS
KECAMATAN : [150] CIJEUNGJING

Data Kemendagri			MFD 2021 Semester 2			
No	Kode	Nama Desa	No	Kode	Nama Desa	Status*
1	32.07.03.2001	HANDAP HERANG	1	3207150001	HANDAP HERANG	2
2	32.07.03.2002	CIHARALANG	2	3207150002	CIHARALANG	2
3	32.07.03.2003	BOJONG-MENGGER	3	3207150003	BOJONG-MENGGER	2
4	32.07.03.2004	KARANGKA MULYAN	4	3207150004	KARANGKA MULYAN	2
5	32.07.03.2005	KERTABUMI	5	3207150005	KERTABUMI	2
6	32.07.03.2006	CIJEUNGJING	6	3207150006	CIJEUNGJING	2
7	32.07.03.2007	PAMALAYAN	7	3207150007	PAMALAYAN	2
8	32.07.03.2008	DEWASARI	8	3207150008	DEWASARI	1
9	32.07.03.2009	UTAMA	9	3207150009	UTAMA	1
10	32.07.03.2010	KERTAHARJA	10	3207150010	KERTAHARJA	2
11	32.07.03.2011	KARANG ANYAR	11	3207150011	KARANG ANYAR	2

Catatan :
*) 1. Perkotaan
2. Perdesaan

https://jabar.bps.go.id

PROVINSI : [32] JAWA BARAT
KAB/KOTA : [07] CIAMIS
KECAMATAN : [160] CISAGA

Data Kemendagri			MFD 2021 Semester 2			
No	Kode	Nama Desa	No	Kode	Nama Desa	Status*
1	32.07.21.2009	DANASARI	1	3207160001	DANASARI	2
2	32.07.21.2002	SIDAMULYA	2	3207160002	SIDAMULYA	2
3	32.07.21.2003	KEPEL	3	3207160003	KEPEL	2
4	32.07.21.2008	MEKARMUKTI	4	3207160004	MEKARMUKTI	1
5	32.07.21.2001	CISAGA	5	3207160005	CISAGA	1
6	32.07.21.2004	WANGUNJAYA	6	3207160006	WANGUNJAYA	2
7	32.07.21.2007	TANJUNGJAYA	7	3207160007	TANJUNGJAYA	2
8	32.07.21.2005	SUKAHURIP	8	3207160008	SUKAHURIP	2
9	32.07.21.2009	BANGUN HARJA	9	3207160009	BANGUN HARJA	2
10	32.07.21.2010	GIRIMUKTI	10	3207160010	GIRIMUKTI	2
11	32.07.21.2011	KARYAMULYA	11	3207160011	KARYAMULYA	2

http://jabar.bps.go.id

Catatan :
*) 1. Perkotaan
2. Perdesaan

DAFTAR DESA/KELURAHAN

PROVINSI : [32] JAWA BARAT
KAB/KOTA : [07] CIAMIS
KECAMATAN : [170] TAMBAKSARI

Data Kemendagri			MFD 2021 Semester 2			
No	Kode	Nama Desa	No	Kode	Nama Desa	Status*
1	32.07.16.2001	TAMBAKSARI	1	3207170001	TAMBAKSARI	2
2	32.07.16.2002	KARANG PANINGAL	2	3207170002	KARANG PANINGAL	2
3	32.07.16.2003	KASO	3	3207170003	KASO	2
4	32.07.16.2004	MEKARSARI	4	3207170004	MEKARSARI	2
5	32.07.16.2005	SUKASARI	5	3207170005	SUKASARI	2
6	32.07.16.2006	KADUPANDAK	6	3207170006	KADUPANDAK	2

Catatan :
*) 1. Perkotaan
2. Perdesaan

https://jabar.bps.go.id

PROVINSI : [32] JAWA BARAT
KAB/KOTA : [07] CIAMIS
KECAMATAN : [180] RANCAH

Data Kemendagri			MFD 2021 Semester 2			
No	Kode	Nama Desa	No	Kode	Nama Desa	Status*
1	32.07.15.2009	KARANGPARI	1	3207180001	KARANGPARI	2
2	32.07.15.2008	BOJONG GEDANG	2	3207180002	BOJONG GEDANG	2
3	32.07.15.2004	CISONTROL	3	3207180003	CISONTROL	2
4	32.07.15.2003	CILEUNGSIR	4	3207180004	CILEUNGSIR	2
5	32.07.15.2002	KIARAPAYUNG	5	3207180005	KIARAPAYUNG	2
6	32.07.15.2006	KAWUNGLA-RANG	6	3207180006	KAWUNGLA-RANG	2
7	32.07.15.2001	RANCAH	7	3207180007	RANCAH	1
8	32.07.15.2005	SITUMANDALA	8	3207180008	SITUMANDALA	2
9	32.07.15.2007	PATAKAHARJA	9	3207180009	PATAKAHARJA	2
10	32.07.15.2010	DADIHARJA	10	3207180010	DADIHARJA	2
11	32.07.15.2011	JANGALA-HARJA	11	3207180011	JANGALA-HARJA	2
12	32.07.15.2012	GIRIHARJA	12	3207180012	GIRIHARJA	2
13	32.07.15.2013	WANGUNSARI	13	3207180013	WANGUNSARI	2

Catatan :
*) 1. Perkotaan
2. Perdesaan

https://jabar.bps.go.id

DAFTAR DESA/KELURAHAN

PROVINSI : [32] JAWA BARAT
KAB/KOTA : [07] CIAMIS
KECAMATAN : [190] RAJADESA

Data Kemendagri			MFD 2021 Semester 2			
No	Kode	Nama Desa	No	Kode	Nama Desa	Status*
1	32.07.13.2002	TANJUNG-SUKUR	1	3207190001	TANJUNG-SUKUR	2
2	32.07.13.2003	TANJUNGSARI	2	3207190002	TANJUNGSARI	2
3	32.07.13.2004	TANJUNGJAYA	3	3207190003	TANJUNGJAYA	2
4	32.07.13.2001	RAJADESA	4	3207190004	RAJADESA	1
5	32.07.13.2009	SIRNABAYA	5	3207190005	SIRNABAYA	1
6	32.07.13.2010	SIRNAJAYA	6	3207190006	SIRNAJAYA	2
7	32.07.13.2011	PURWARAJA	7	3207190007	PURWARAJA	2
8	32.07.13.2005	ANDAPRAJA	8	3207190008	ANDAPRAJA	2
9	32.07.13.2006	SUKAHARJA	9	3207190009	SUKAHARJA	2
10	32.07.13.2008	TIGAHERANG	10	3207190010	TIGAHERANG	2
11	32.07.13.2007	SUKAJAYA	11	3207190011	SUKAJAYA	2

Catatan :
*) 1. Perkotaan
2. Perdesaan

https://jabar.bps.go.id

PROVINSI : [32] JAWA BARAT
KAB/KOTA : [07] CIAMIS
KECAMATAN : [200] SUKADANA

Data Kemendagri			MFD 2021 Semester 2			
No	Kode	Nama Desa	No	Kode	Nama Desa	Status*
1	32.07.14.2006	CIPARIGI	1	3207200001	CIPARIGI	2
2	32.07.14.2005	BUNTER	2	3207200002	BUNTER	2
3	32.07.14.2003	MARGAHARJA	3	3207200003	MARGAHARJA	2
4	32.07.14.2004	MARGAJAYA	4	3207200004	MARGAJAYA	2
5	32.07.14.2001	SUKADANA	5	3207200005	SUKADANA	2
6	32.07.14.2002	SALAKARIA	6	3207200006	SALAKARIA	2

Catatan :
*) 1. Perkotaan
2. Perdesaan

https://jabar.bps.go.id

DAFTAR DESA/KELURAHAN

PROVINSI : [32] JAWA BARAT
KAB/KOTA : [07] CIAMIS
KECAMATAN : [210] CIAMIS

Data Kemendagri			MFD 2021 Semester 2			
No	Kode	Nama Desa	No	Kode	Nama Desa	Status*
1	32.07.01.2011	IMBANAGARA RAYA	1	3207210001	IMBANAGARA RAYA	1
2	32.07.01.2009	CISADAP	2	3207210002	CISADAP	2
3	32.07.01.2010	IMBANAGARA	3	3207210003	IMBANAGARA	1
4	32.07.01.1007	SINDANGRASA	4	3207210004	SINDANGRASA	1
5	32.07.01.2012	PANYINGKIRAN	5	3207210005	PANYINGKIRAN	1
6	32.07.01.2008	PAWINDAN	6	3207210006	PAWINDAN	1
7	32.07.01.1006	LINGGASARI	7	3207210007	LINGGASARI	1
8	32.07.01.1001	CIAMIS	8	3207210008	CIAMIS	1
9	32.07.01.1005	BENTENG	9	3207210009	BENTENG	1
10	32.07.01.1004	CIGEMBOR	10	3207210010	CIGEMBOR	1
11	32.07.01.1002	KERTASARI	11	3207210011	KERTASARI	1
12	32.07.01.1003	MALEBER	12	3207210012	MALEBER	1

Catatan :
*) 1. Perkotaan
2. Perdesaan

https://jabar.bps.go.id

PROVINSI : [32] JAWA BARAT
KAB/KOTA : [07] CIAMIS
KECAMATAN : [211] BAREGBEG

Data Kemendagri			MFD 2021 Semester 2			
No	Kode	Nama Desa	No	Kode	Nama Desa	Status*
1	32.07.23.2002	SUKAMAJU	1	3207211001	SUKAMAJU	1
2	32.07.23.2003	MEKARJAYA	2	3207211002	MEKARJAYA	1
3	32.07.23.2004	SAGULING	3	3207211003	SAGULING	2
4	32.07.23.2001	BAREGBEG	4	3207211004	BAREGBEG	1
5	32.07.23.2005	PETIRHILIR	5	3207211005	PETIRHILIR	2
6	32.07.23.2006	PUSAKANAGA-RA	6	3207211006	PUSAKANAGA-RA	2
7	32.07.23.2008	KARANGAM-PEL	7	3207211007	KARANGAM-PEL	2
8	32.07.23.2007	JELAT	8	3207211008	JELAT	2
9	32.07.23.2009	SUKAMULYA	9	3207211009	SUKAMULYA	2

Catatan :
*) 1. Perkotaan
2. Perdesaan

https://jabar.bps.go.id

DAFTAR DESA/KELURAHAN

PROVINSI : [32] JAWA BARAT
KAB/KOTA : [07] CIAMIS
KECAMATAN : [220] CIKONENG

Data Kemendagri			MFD 2021 Semester 2			
No	Kode	Nama Desa	No	Kode	Nama Desa	Status*
1	32.07.02.2011	PANARAGAN	1	3207220001	PANARAGAN	2
2	32.07.02.2002	MARGALUYU	2	3207220002	MARGALUYU	1
3	32.07.02.2001	CIKONENG	3	3207220003	CIKONENG	1
4	32.07.02.2013	KUJANG	4	3207220004	KUJANG	1
5	32.07.02.2012	DARMACAANG	5	3207220005	DARMACAANG	2
6	32.07.02.2014	NASOL	6	3207220006	NASOL	2
7	32.07.02.2003	SINDANGSARI	7	3207220007	SINDANGSARI	1
8	32.07.02.2016	CIMARI	8	3207220008	CIMARI	1
9	32.07.02.2017	GEGEMPALAN	9	3207220009	GEGEMPALAN	2

Catatan :
*) 1. Perkotaan
2. Perdesaan

https://jabar.bps.go.id

PROVINSI : [32] JAWA BARAT
KAB/KOTA : [07] CIAMIS
KECAMATAN : [221] SINDANGKASIH

Data Kemendagri			MFD 2021 Semester 2			
No	Kode	Nama Desa	No	Kode	Nama Desa	Status*
1	32.07.22.2006	SUKAMANAH	1	3207221001	SUKAMANAH	1
2	32.07.22.2005	SUKARAJA	2	3207221002	SUKARAJA	1
3	32.07.22.2004	BUDIHARJA	3	3207221003	BUDIHARJA	2
4	32.07.22.2003	BUDIASIH	4	3207221004	BUDIASIH	2
5	32.07.22.2002	GUNUNGCUPU	5	3207221005	GUNUNGCUPU	1
6	32.07.22.2001	SINDANG-KASIH	6	3207221006	SINDANG-KASIH	1
7	32.07.22.2007	SUKASENANG	7	3207221007	SUKASENANG	1
8	32.07.22.2008	SUKARESIK	8	3207221008	SUKARESIK	2
9	32.07.22.2009	WANASIGRA	9	3207221009	WANASIGRA	1

Catatan :
*) 1. Perkotaan
2. Perdesaan

https://jabar.bps.go.id

DAFTAR DESA/KELURAHAN

PROVINSI : [32] JAWA BARAT
KAB/KOTA : [07] CIAMIS
KECAMATAN : [230] CIHAURBEUTI

Data Kemendagri			MFD 2021 Semester 2			
No	Kode	Nama Desa	No	Kode	Nama Desa	Status*
1	32.07.06.2001	SUKAMULYA	1	3207230001	SUKAMULYA	1
2	32.07.06.2011	SUKAHAJI	2	3207230002	SUKAHAJI	1
3	32.07.06.2002	SUKAHURIP	3	3207230003	SUKAHURIP	2
4	32.07.06.2004	SUKAMAJU	4	3207230004	SUKAMAJU	2
5	32.07.06.2003	CIJULANG	5	3207230005	CIJULANG	2
6	32.07.06.2005	SUKASETIA	6	3207230006	SUKASETIA	2
7	32.07.06.2006	SUMBERJAYA	7	3207230007	SUMBERJAYA	1
8	32.07.06.2007	CIHAURBEUTI	8	3207230008	CIHAURBEUTI	1
9	32.07.06.2008	PASIRTAMIANG	9	3207230009	PASIRTAMIANG	2
10	32.07.06.2009	PADAMULYA	10	3207230010	PADAMULYA	2
11	32.07.06.2010	PAMOKOLAN	11	3207230011	PAMOKOLAN	2

Catatan :
*) 1. Perkotaan
2. Perdesaan

https://jabar.bps.go.id

PROVINSI : [32] JAWA BARAT
KAB/KOTA : [07] CIAMIS
KECAMATAN : [240] SADANANYA

Data Kemendagri			MFD 2021 Semester 2			
No	Kode	Nama Desa	No	Kode	Nama Desa	Status*
1	32.07.04.2008	MEKARJADI	1	3207240001	MEKARJADI	1
2	32.07.04.2007	SUKAJADI	2	3207240002	SUKAJADI	2
3	32.07.04.2003	WERASARI	3	3207240003	WERASARI	2
4	32.07.04.2004	MANGKUBUMI	4	4320724004	MANGKUBUMI	2
5	32.07.04.2006	BENDASARI	5	3207240005	BENDASARI	2
6	32.07.04.2002	SADANANYA	6	3207240006	SADANANYA	2
7	32.07.04.2005	TANJUNGSARI	7	3207240007	TANJUNGSARI	2
8	32.07.04.2001	GUNUNGSARI	8	3207240008	GUNUNGSARI	2

Catatan :
*) 1. Perkotaan
2. Perdesaan

https://jabar.bps.go.id

DAFTAR DESA/KELURAHAN

PROVINSI : [32] JAWA BARAT
KAB/KOTA : [07] CIAMIS
KECAMATAN : [250] CIPAKU

Data Kemendagri			MFD 2021 Semester 2			
No	Kode	Nama Desa	No	Kode	Nama Desa	Status*
1	32.07.11.2007	MUKTISARI	1	3207250001	MUKTISARI	1
2	32.07.11.2008	MEKARSARI	2	3207250002	MEKARSARI	2
3	32.07.11.2001	BUNISEURI	3	3207250003	BUNISEURI	1
4	32.07.11.2009	PUSAKASARI	4	3207250004	PUSAKASARI	1
5	32.07.11.2003	JALATRANG	5	3207250005	JALATRANG	2
6	32.07.11.2013	SUKAWENING	6	3207250006	SUKAWENING	2
7	32.07.11.2004	CIPAKU	7	3207250007	CIPAKU	2
8	32.07.11.2010	BANGBAYANG	8	3207250008	BANGBAYANG	1
9	32.07.11.2005	CIEURIH	9	3207250009	CIEURIH	2
10	32.07.11.2011	SELAMANIK	10	3207250010	SELAMANIK	2
11	32.07.11.2002	SELACAI	11	3207250011	SELACAI	2
12	32.07.11.2006	GEREBA	12	3207250012	GEREBA	1
13	32.07.11.2012	CIAKAR	13	3207250013	CIAKAR	1

Catatan :
*) 1. Perkotaan
2. Perdesaan

https://jabar.bps.go.id

PROVINSI : [32] JAWA BARAT
KAB/KOTA : [07] CIAMIS
KECAMATAN : [260] JATINAGARA

Data Kemendagri			MFD 2021 Semester 2			
No	Kode	Nama Desa	No	Kode	Nama Desa	Status*
1	32.07.12.2003	CINTANAGARA	1	3207260001	CINTANAGARA	2
2	32.07.12.2006	BAYASARI	2	3207260002	BAYASARI	2
3	32.07.12.2001	JATINAGARA	3	3207260003	JATINAGARA	2
4	32.07.12.2004	DAYEUH LUHUR	4	3207260004	DAYEUH LUHUR	2
5	32.07.12.2002	SUKANAGARA	5	3207260005	SUKANAGARA	2
6	32.07.12.2005	MULYASARI	6	3207260006	MULYASARI	2

Catatan :
*) 1. Perkotaan
2. Perdesaan

https://jabar.bps.go.id

DAFTAR DESA/KELURAHAN

PROVINSI : [32] JAWA BARAT
KAB/KOTA : [07] CIAMIS
KECAMATAN : [270] PANAWANGAN

Data Kemendagri			MFD 2021 Semester 2			
No	Kode	Nama Desa	No	Kode	Nama Desa	Status*
1	32.07.10.2006	KERTAYASA	1	3207270001	KERTAYASA	2
2	32.07.10.2012	KARANG PANINGAL	2	3207270002	KARANG PANINGAL	2
3	32.07.10.2007	INDRAGIRI	3	3207270003	INDRAGIRI	2
4	32.07.10.2001	PANAWANGAN	4	3207270004	PANAWANGAN	1
5	32.07.10.2002	SAGALA-HERANG	5	3207270005	SAGALA-HERANG	2
6	32.07.10.2003	NAGARAPA-GEUH	6	3207270006	NAGARAPA-GEUH	2
7	32.07.10.2005	NAGARAJAYA	7	3207270007	NAGARAJAYA	2
8	32.07.10.2004	NAGARAJATI	8	3207270008	NAGARAJATI	2
9	32.07.10.2010	JAGABAYA	9	3207270009	JAGABAYA	2
10	32.07.10.2008	CINYASAG	10	3207270010	CINYASAG	2
11	32.07.10.2011	GARDUJAYA	11	3207270011	GARDUJAYA	2
12	32.07.10.2009	SADAPAINGAN	12	3207270012	SADAPAINGAN	2
13	32.07.10.2013	BANGUNJAYA	13	3207270013	BANGUNJAYA	2
14	32.07.10.2014	GIRILAYA	14	3207270014	GIRILAYA	2
15	32.07.10.2015	KERTAJAYA	15	3207270015	KERTAJAYA	2
16	32.07.10.2016	NAGARA WANGI	16	3207270016	NAGARA WANGI	2
17	32.07.10.2018	NATANEGARA	17	3207270017	NATANEGARA	2
18	32.07.10.2017	MEKARBUANA	18	3207270018	MEKARBUANA	2

Catatan :
*) 1. Perkotaan
2. Perdesaan

https://jabar.bps.go.id

PROVINSI : [32] JAWA BARAT
KAB/KOTA : [07] CIAMIS
KECAMATAN : [280] KAWALI

Data Kemendagri			MFD 2021 Semester 2			
No	Kode	Nama Desa	No	Kode	Nama Desa	Status*
1	32.07.09.2014	SINDANGSARI	1	3207280001	SINDANGSARI	2
2	32.07.09.2001	KAWALI	2	3207280002	KAWALI	1
3	32.07.09.2004	KARANGPAWI TAN	3	3207280003	KARANGPAWI TAN	1
4	32.07.09.2015	KAWALIMUKTI	4	3207280004	KAWALIMUKTI	1
5	32.07.09.2002	TALAGASARI	5	3207280005	TALAGASARI	2
6	32.07.09.2016	SELASARI	6	3207280006	SELASARI	2
7	32.07.09.2006	MARGAMULYA	7	3207280007	MARGAMULYA	2
8	32.07.09.2005	WINDURAJA	8	3207280008	WINDURAJA	1
9	32.07.09.2013	PURWASARI	9	3207280009	PURWASARI	2
10	32.07.09.2011	CITEUREUP	10	3207280010	CITEUREUP	2
11	32.07.09.2019	LINGGAPURA	11	3207280011	LINGGAPURA	1

Catatan :
*) 1. Perkotaan
2. Perdesaan

https://jabar.bps.go.id

DAFTAR DESA/KELURAHAN

PROVINSI : [32] JAWA BARAT
KAB/KOTA : [07] CIAMIS
KECAMATAN : [281] LUMBUNG

Data Kemendagri			MFD 2021 Semester 2			
No	Kode	Nama Desa	No	Kode	Nama Desa	Status*
1	32.07.25.2001	CIKUPA	1	3207281001	CIKUPA	2
2	32.07.25.2002	SUKARAHARJA	2	3207281002	SUKARAHARJA	2
3	32.07.25.2005	AWILUAR	3	3207281003	AWILUAR	1
4	32.07.25.2003	LUMBUNG	4	3207281004	LUMBUNG	1
5	32.07.25.2006	DARMARAJA	5	3207281005	DARMARAJA	2
6	32.07.25.2004	LUMBUNGSARI	6	3207281006	LUMBUNGSARI	2
7	32.07.25.2007	RAWA	7	3207281007	RAWA	2
8	32.07.25.2008	SADEWATA	8	3207281008	SADEWATA	2

Catatan :
*) 1. Perkotaan
2. Perdesaan

https://jabar.bps.go.id

PROVINSI : [32] JAWA BARAT
KAB/KOTA : [07] CIAMIS
KECAMATAN : [290] PANJALU

Data Kemendagri			MFD 2021 Semester 2			
No	Kode	Nama Desa	No	Kode	Nama Desa	Status*
1	32.07.08.2013	MANDALARE	1	3207290001	MANDALARE	2
2	32.07.08.2002	KERTAMAN-DALA	2	3207290002	KERTAMAN-DALA	2
3	32.07.08.2003	CIOMAS	3	3207290003	CIOMAS	2
4	32.07.08.2004	SANDINGTA-MAN	4	3207290004	SANDINGTA-MAN	2
5	32.07.08.2005	MAPARAH	5	3207290005	MAPARAH	2
6	32.07.08.2001	PANJALU	6	3207290006	PANJALU	1
7	32.07.08.2009	BAHARA	7	3207290007	BAHARA	2
8	32.07.08.2012	HUJUNGTIWU	8	3207290008	HUJUNGTIWU	2

Catatan :
*) 1. Perkotaan
2. Perdesaan

https://jabar.bps.go.id

DAFTAR DESA/KELURAHAN

PROVINSI : [32] JAWA BARAT
KAB/KOTA : [07] CIAMIS
KECAMATAN : [291] SUKAMANTRI

Data Kemendagri			MFD 2021 Semester 2			
No	Kode	Nama Desa	No	Kode	Nama Desa	Status*
1	32.07.24.2002	TENGGERRA-HARJA	1	3207291001	TENGGERRA-HARJA	2
2	32.07.24.2001	SUKAMANTRI	2	3207291002	SUKAMANTRI	1
3	32.07.24.2003	CIBEUREUM	3	3207291003	CIBEUREUM	2
4	32.07.24.2004	SINDANGLAYA	4	3207291004	SINDANGLAYA	2
5	32.07.24.2005	MEKARWANGI	5	3207291005	MEKARWANGI	2

Catatan :
*) 1. Perkotaan
2. Perdesaan

https://jabar.bps.go.id

PROVINSI : [32] JAWA BARAT
KAB/KOTA : [07] CIAMIS
KECAMATAN : [300] PANUMBANGAN

Data Kemendagri			MFD 2021 Semester 2			
No	Kode	Nama Desa	No	Kode	Nama Desa	Status*
1	32.07.07.2001	MEDANG LAYANG	1	3207300001	MEDANG LAYANG	1
2	32.07.07.2002	PANUMBANG AN	2	3207300002	PANUMBANG AN	1
3	32.07.07.2008	TANJUNG MULYA	3	3207300003	TANJUNG MULYA	1
4	32.07.07.2011	KERTARA-HARJA	4	3207300004	KERTARA-HARJA	2
5	32.07.07.2003	SUKAKERTA	5	3207300005	SUKAKERTA	2
6	32.07.07.2004	GOLAT	6	3207300006	GOLAT	2
7	32.07.07.2005	SINDANG-HERANG	7	3207300007	SINDANG-HERANG	1
8	32.07.07.2012	SINDANG-MUKTI	8	3207300008	SINDANG-MUKTI	2
9	32.07.07.2010	JAYAGIRI	9	3207300009	JAYAGIRI	2
10	32.07.07.2006	BANJARANG-SANA	10	3207300010	BANJARANG-SANA	2
11	32.07.07.2009	PAYUNGSARI	11	3207300011	PAYUNGSARI	2
12	32.07.07.2007	PAYUNG AGUNG	12	3207300012	PAYUNG AGUNG	2
13	32.07.07.2013	SINDANGBA-RANG	13	3207300013	SINDANGBA-RANG	2
14	32.07.07.2014	BUANAMEKAR	14	3207300014	BUANAMEKAR	2

Catatan :
*) 1. Perkotaan
2. Perdesaan

https://jabar.bps.go.id

https://jabar.bps.go.id

KABUPATEN KUNINGAN

https://jabar.bps.go.id

https://jabar.bps.go.id

PROVINSI : [32] JAWA BARAT
KAB/KOTA : [08] KUNINGAN

Data Kemendagri			MFD 2021 Semester 2		
No	Kode	Nama Kecamatan	No	Kode	Nama Kecamatan
1	32.08.17	DARMA	1	3208010	DARMA
2	32.08.01	KADUGEDE	2	3208020	KADUGEDE
3	32.08.20	NUSAHERANG	3	3208021	NUSAHERANG
4	32.08.02	CINIRU	4	3208030	CINIRU
5	32.08.26	HANTARA	5	3208031	HANTARA
6	32.08.15	SELAJAMBE	6	3208040	SELAJAMBE
7	32.08.03	SUBANG	7	3208050	SUBANG
8	32.08.25	CILEBAK	8	3208051	CILEBAK
9	32.08.04	CIWARU	9	3208060	CIWARU
10	32.08.29	KARANG KANCANA	10	3208061	KARANGKANCANA
11	32.08.05	CIBINGBIN	11	3208070	CIBINGBIN
12	32.08.28	CIBEUREUM	12	3208071	CIBEUREUM
13	32.08.06	LURAGUNG	13	3208080	LURAGUNG
14	32.08.24	CIMAHI	14	3208081	CIMAHI
15	32.08.11	CIDAHU	15	3208090	CIDAHU
16	32.08.27	KALIMANGGIS	16	3208091	KALIMANGGIS
17	32.08.10	CIAWIGEBANG	17	3208100	CIAWIGEBANG
18	32.08.21	CIPICUNG	18	3208101	CIPICUNG
19	32.08.07	LEBAKWANGI	19	3208110	LEBAKWANGI
20	32.08.30	MALEBER	20	3208111	MALEBER
21	32.08.08	GARAWANGI	21	3208120	GARAWANGI
22	32.08.31	SINDANG AGUNG	22	3208121	SINDANGAGUNG

https://jabar.bps.go.id

DAFTAR KECAMATAN

PROVINSI : [32] JAWA BARAT
KAB/KOTA : [08] KUNINGAN

Data Kemendagri			MFD 2021 Semester 2		
No	Kode	Nama Kecamatan	No	Kode	Nama Kecamatan
23	32.08.09	KUNINGAN	23	3208130	KUNINGAN
24	32.08.18	CIGUGUR	24	3208140	CIGUGUR
25	32.08.16	KRAMATMULYA	25	3208150	KRAMATMULYA
26	32.08.12	JALAKSANA	26	3208160	JALAKSANA
27	32.08.23	JAPARA	27	3208161	JAPARA
28	32.08.13	CILIMUS	28	3208170	CILIMUS
29	32.08.32	CIGANDAMEKAR	29	3208171	CIGANDAMEKAR
30	32.08.14	MANDIRANCAN	30	3208180	MANDIRANCAN
31	32.08.22	PANCALANG	31	3208181	PANCALANG
32	32.08.19	PASAWAHAN	32	3208190	PASAWAHAN

https://jabar.bps.go.id

JUMLAH DESA/KELURAHAN PER KECAMATAN

PROVINSI : [32] JAWA BARAT
KAB/KOTA : [08] KUNINGAN

Data Kemendagri				MFD 2021 Semester 2			
No	Kode	Nama Kecamatan	Jml Desa	No	Kode	Nama Kecamatan	Jml Desa
1	32.08.17	DARMA	19	1	3208010	DARMA	19
2	32.08.01	KADUGEDE	12	2	3208020	KADUGEDE	12
3	32.08.20	NUSAHERANG	8	3	3208021	NUSAHERANG	8
4	32.08.02	CINIRU	9	4	3208030	CINIRU	9
5	32.08.26	HANTARA	8	5	3208031	HANTARA	8
6	32.08.15	SELAJAMBE	7	6	3208040	SELAJAMBE	7
7	32.08.03	SUBANG	7	7	3208050	SUBANG	7
8	32.08.25	CILEBAK	7	8	3208051	CILEBAK	7
9	32.08.04	CIWARU	12	9	3208060	CIWARU	12
10	32.08.29	KARANG KAN-CANA	9	10	3208061	KARANGKAN-CANA	9
11	32.08.05	CIBINGBIN	10	11	3208070	CIBINGBIN	10
12	32.08.28	CIBEUREUM	8	12	3208071	CIBEUREUM	8
13	32.08.06	LURAGUNG	16	13	3208080	LURAGUNG	16
14	32.08.24	CIMAHI	10	14	3208081	CIMAHI	10
15	32.08.11	CIDAHU	12	15	3208090	CIDAHU	12
16	32.08.27	KALIMANGGIS	6	16	3208091	KALIMANGGIS	6
17	32.08.10	CIAWIGEBANG	24	17	3208100	CIAWIGEBANG	24
18	32.08.21	CIPICUNG	10	18	3208101	CIPICUNG	10
19	32.08.07	LEBAKWANGI	13	19	3208110	LEBAKWANGI	13
20	32.08.30	MALEBER	16	20	3208111	MALEBER	16
21	32.08.08	GARAWANGI	17	21	3208120	GARAWANGI	17

https://jabar.bps.go.id

JUMLAH DESA/KELURAHAN PER KECAMATAN

PROVINSI : [32] JAWA BARAT
KAB/KOTA : [08] KUNINGAN

Data Kemendagri				MFD 2021 Semester 2			
No	Kode	Nama Kecamatan	Jml Desa	No	Kode	Nama Kecamatan	Jml Desa
22	32.08.31	SINDANG AGUNG	12	22	3208121	SINDANGAGUNG	12
23	32.08.09	KUNINGAN	16	23	3208130	KUNINGAN	16
24	32.08.18	CIGUGUR	10	24	3208140	CIGUGUR	10
25	32.08.16	KRAMATMULYA	14	25	3208150	KRAMATMULYA	14
26	32.08.12	JALAKSANA	15	26	3208160	JALAKSANA	15
27	32.08.23	JAPARA	10	27	3208161	JAPARA	10
28	32.08.13	CILIMUS	13	28	3208170	CILIMUS	13
29	32.08.32	CIGANDAMEKAR	11	29	3208171	CIGANDAMEKAR	11
30	32.08.14	MANDIRANCAN	12	30	3208180	MANDIRANCAN	12
31	32.08.22	PANCALANG	13	31	3208181	PANCALANG	13
32	32.08.19	PASAWAHAN	10	32	3208190	PASAWAHAN	10

https://jabar.bps.go.id

PROVINSI : [32] JAWA BARAT
KAB/KOTA : [08] KUNINGAN
KECAMATAN : [010] DARMA

Data Kemendagri			MFD 2021 Semester 2			
No	Kode	Nama Desa	No	Kode	Nama Desa	Status*
1	32.08.17.2001	CIMENGA	1	3208010001	CIMENGA	2
2	32.08.17.2018	TUGUMULYA	2	3208010002	TUGUMULYA	2
3	32.08.17.2002	CAGEUR	3	3208010003	CAGEUR	2
4	32.08.17.2017	SAKERTA TIMUR	4	3208010004	SAKERTA TIMUR	2
5	32.08.17.2003	SAKERTA BARAT	5	3208010005	SAKERTA BARAT	2
6	32.08.17.2004	SUKARASA	6	3208010006	SUKARASA	2
7	32.08.17.2005	PANINGGARAN	7	3208010007	PANINGGARAN	2
8	32.08.17.2006	CIPASUNG	8	3208010008	CIPASUNG	2
9	32.08.17.2007	KAWAHMANUK	9	3208010009	KAWAHMANUK	2
10	32.08.17.2008	CIKUPA	10	3208010010	CIKUPA	1
11	32.08.17.2009	PARUNG	11	3208010011	PARUNG	1
12	32.08.17.2010	DARMA	12	3208010012	DARMA	1
13	32.08.17.2011	JAGARA	13	3208010013	JAGARA	1
14	32.08.17.2012	BAKOM	14	3208010014	BAKOM	1
15	32.08.17.2013	KARANGANYAR	15	3208010015	KARANGANYAR	1
16	32.08.17.2016	GUNUNGSIRAH	16	3208010016	GUNUNGSIRAH	2
17	32.08.17.2019	SITUSARI	17	3208010017	SITUSARI	2
18	32.08.17.2014	KARANGSARI	18	3208010018	KARANGSARI	2
19	32.08.17.2015	SAGARAHIANG	19	3208010019	SAGARAHIANG	2

Catatan :
*) 1. Perkotaan
2. Perdesaan

https://jabar.bps.go.id

DAFTAR DESA/KELURAHAN

PROVINSI : [32] JAWA BARAT
KAB/KOTA : [08] KUNINGAN
KECAMATAN : [020] KADUGEDE

Data Kemendagri			MFD 2021 Semester 2			
No	Kode	Nama Desa	No	Kode	Nama Desa	Status*
1	32.08.01.2012	MARGABAKTI	1	3208020003	MARGABAKTI	2
2	32.08.01.2001	SINDANGJAWA	2	3208020004	SINDANGJAWA	2
3	32.08.01.2005	KADUGEDE	3	3208020009	KADUGEDE	1
4	32.08.01.2002	CIKETAK	4	3208020010	CIKETAK	1
5	32.08.01.2003	NANGKA	5	3208020011	NANGKA	2
6	32.08.01.2004	WINDUJANTEN	6	3208020012	WINDUJANTEN	1
7	32.08.01.2007	CIPONDOK	7	3208020013	CIPONDOK	1
8	32.08.01.2006	BABATAN	8	3208020014	BABATAN	1
9	32.08.01.2008	BAYUNING	9	3208020015	BAYUNING	1
10	32.08.01.2010	CIHERANG	10	3208020017	CIHERANG	2
11	32.08.01.2009	TINGGAR	11	3208020018	TINGGAR	2
12	32.08.01.2011	CISUKADANA	12	3208020019	CISUKADANA	2

Catatan :
*) 1. Perkotaan
2. Perdesaan

https://jabar.bps.go.id

PROVINSI : [32] JAWA BARAT
KAB/KOTA : [08] KUNINGAN
KECAMATAN : [021] NUSAHERANG

Data Kemendagri			MFD 2021 Semester 2			
No	Kode	Nama Desa	No	Kode	Nama Desa	Status*
1	32.08.20.2001	HAURKUNING	1	3208021001	HAURKUNING	2
2	32.08.20.2002	KERTAYUGA	2	3208021002	KERTAYUGA	2
3	32.08.20.2003	WINDUSARI	3	3208021003	WINDUSARI	2
4	32.08.20.2004	NUSAHERANG	4	3208021004	NUSAHERANG	1
5	32.08.20.2007	KERTAWIRAMA	5	3208021005	KERTAWIRAMA	2
6	32.08.20.2006	CIKADU	6	3208021006	CIKADU	2
7	32.08.20.2005	JAMBAR	7	3208021007	JAMBAR	2
8	32.08.20.2008	CIASIH	8	3208021008	CIASIH	2

Catatan :
*) 1. Perkotaan
2. Perdesaan

https://jabar.bps.go.id

DAFTAR DESA/KELURAHAN

PROVINSI : [32] JAWA BARAT
KAB/KOTA : [08] KUNINGAN
KECAMATAN : [030] CINIRU

Data Kemendagri			MFD 2021 Semester 2			
No	Kode	Nama Desa	No	Kode	Nama Desa	Status*
1	32.08.02.2008	GUNUNG-MANIK	1	3208030009	GUNUNG-MANIK	2
2	32.08.02.2001	PINARA	2	3208030010	PINARA	2
3	32.08.02.2003	CIPEDES	3	3208030011	CIPEDES	2
4	32.08.02.2009	PAMUPUKAN	4	3208030012	PAMUPUKAN	2
5	32.08.02.2002	CIJEMIT	5	3208030013	CIJEMIT	2
6	32.08.02.2004	CINIRU	6	3208030014	CINIRU	2
7	32.08.02.2005	RAMBATAN	7	3208030015	RAMBATAN	2
8	32.08.02.2006	LONGKEWANG	8	3208030016	LONGKEWANG	2
9	32.08.02.2007	MUNGKAL DATAR	9	3208030017	MUNGKAL DATAR	2

Catatan :
*) 1. Perkotaan
2. Perdesaan

https://jabar.bps.go.id

PROVINSI : [32] JAWA BARAT
KAB/KOTA : [08] KUNINGAN
KECAMATAN : [031] HANTARA

Data Kemendagri			MFD 2021 Semester 2			
No	Kode	Nama Desa	No	Kode	Nama Desa	Status*
1	32.08.26.2003	TUNDAGAN	1	3208031001	TUNDAGAN	2
2	32.08.26.2004	BUNIGEULIS	2	3208031002	BUNIGEULIS	2
3	32.08.26.2005	HANTARA	3	3208031003	HANTARA	2
4	32.08.26.2007	CIKONDANG	4	3208031004	CIKONDANG	2
5	32.08.26.2002	PASIRAGUNG	5	3208031005	PASIRAGUNG	2
6	32.08.26.2001	CITAPEN	6	3208031006	CITAPEN	2
7	32.08.26.2008	PAKAPASAN HILIR	7	3208031007	PAKAPASAN HILIR	2
8	32.08.26.2006	PAKAPASAN GIRANG	8	3208031008	PAKAPASAN GIRANG	2

Catatan :
*) 1. Perkotaan
2. Perdesaan

https://jabar.bps.go.id

DAFTAR DESA/KELURAHAN

PROVINSI : [32] JAWA BARAT
KAB/KOTA : [08] KUNINGAN
KECAMATAN : [040] SELAJAMBE

Data Kemendagri			MFD 2021 Semester 2			
No	Kode	Nama Desa	No	Kode	Nama Desa	Status*
1	32.08.15.2002	CANTILAN	1	3208040001	CANTILAN	2
2	32.08.15.2001	SELAJAMBE	2	3208040002	SELAJAMBE	2
3	32.08.15.2003	CIBERUNG	3	3208040003	CIBERUNG	2
4	32.08.15.2004	KUTAWA RINGIN	4	3208040004	KUTAWA RINGIN	2
5	32.08.15.2006	BAGAWAT	5	3208040005	BAGAWAT	2
6	32.08.15.2005	JAMBERAMA	6	3208040006	JAMBERAMA	2
7	32.08.15.2007	PADAHURIP	7	3208040007	PADAHURIP	2

Catatan :
*) 1. Perkotaan
2. Perdesaan

https://jabar.bps.go.id

PROVINSI : [32] JAWA BARAT
KAB/KOTA : [08] KUNINGAN
KECAMATAN : [050] SUBANG

Data Kemendagri			MFD 2021 Semester 2			
No	Kode	Nama Desa	No	Kode	Nama Desa	Status*
1	32.08.03.2001	TANGKOLO	1	3208050001	TANGKOLO	2
2	32.08.03.2002	PAMULIHAN	2	3208050002	PAMULIHAN	2
3	32.08.03.2007	JATISARI	3	3208050003	JATISARI	2
4	32.08.03.2003	SUBANG	4	3208050004	SUBANG	2
5	32.08.03.2006	BANGUNJAYA	5	3208050005	BANGUNJAYA	2
6	32.08.03.2004	GUNUNGACI	6	3208050006	GUNUNGACI	2
7	32.08.03.2005	SITUGEDE	7	3208050007	SITUGEDE	2

Catatan :
*) 1. Perkotaan
2. Perdesaan

https://jabar.bps.go.id

DAFTAR DESA/KELURAHAN

PROVINSI : [32] JAWA BARAT
KAB/KOTA : [08] KUNINGAN
KECAMATAN : [051] CILEBAK

Data Kemendagri			MFD 2021 Semester 2			
No	Kode	Nama Desa	No	Kode	Nama Desa	Status*
1	32.08.25.2001	MANDAPA-JAYA	1	3208051001	MANDAPA-JAYA	2
2	32.08.25.2002	LEGOK HERANG	2	3208051002	LEGOK HERANG	2
3	32.08.25.2003	BUNGURBERES	3	3208051003	BUNGURBERES	2
4	32.08.25.2004	CILEBAK	4	3208051004	CILEBAK	2
5	32.08.25.2005	JALATRANG	5	3208051005	JALATRANG	2
6	632.08.25.200	PATALA	6	3208051006	PATALA	2
7	32.08.25.2007	CILIMUSARI	7	3208051007	CILIMUSARI	2

Catatan :
*) 1. Perkotaan
2. Perdesaan

https://jabar.bps.go.id

PROVINSI : [32] JAWA BARAT
KAB/KOTA : [08] KUNINGAN
KECAMATAN : [060] CIWARU

Data Kemendagri			MFD 2021 Semester 2			
No	Kode	Nama Desa	No	Kode	Nama Desa	Status*
1	32.08.04.2008	CITUNDUN	1	3208060001	CITUNDUN	2
2	32.08.04.2007	SAGARATEN	2	3208060006	SAGARATEN	2
3	32.08.04.2001	SUMBERJAYA	3	3208060007	SUMBERJAYA	2
4	32.08.04.2009	LEBAKHERANG	4	3208060008	LEBAKHERANG	2
5	32.08.04.2002	CILAYUNG	5	3208060009	CILAYUNG	2
6	32.08.04.2003	CIWARU	6	3208060010	CIWARU	2
7	32.08.04.2011	LINGGA JAYA	7	3208060011	LINGGA JAYA	2
8	32.08.04.2010	KARANGBARU	8	3208060013	KARANGBARU	2
9	32.08.04.2004	GARAJATI	9	3208060014	GARAJATI	2
10	32.08.04.2005	BAOK	10	3208060016	BAOK	2
11	32.08.04.2006	ANDAMUI	11	3208060017	ANDAMUI	2
12	32.08.04.2012	CITIKUR	12	3208060018	CITIKUR	2

Catatan :
*) 1. Perkotaan
2. Perdesaan

https://jabar.bps.go.id

DAFTAR DESA/KELURAHAN

PROVINSI : [32] JAWA BARAT
KAB/KOTA : [08] KUNINGAN
KECAMATAN : [061] KARANGKANCANA

Data Kemendagri			MFD 2021 Semester 2			
No	Kode	Nama Desa	No	Kode	Nama Desa	Status*
1	32.08.29.2006	MARGACINA	1	3208061001	MARGACINA	2
2	32.08.29.2007	JABRANTI	2	3208061002	JABRANTI	2
3	32.08.29.2001	KARANGKAN-CANA	3	3208061003	KARANGKAN-CANA	2
4	32.08.29.2002	KADUAGUNG	4	3208061004	KADUAGUNG	2
5	32.08.29.2003	SEGONG	5	3208061005	SEGONG	2
6	32.08.29.2004	TANJUNGKER-TA	6	3208061006	TANJUNGKER-TA	2
7	32.08.29.2005	SUKASARI	7	3208061007	SUKASARI	2
8	32.08.29.2008	SIMPAYJAYA	8	3208061008	SIMPAYJAYA	2
9	32.08.29.2009	CIHANJARO	9	3208061009	CIHANJARO	2

Catatan :
*) 1. Perkotaan
2. Perdesaan

https://jabar.bps.go.id

PROVINSI : [32] JAWA BARAT
KAB/KOTA : [08] KUNINGAN
KECAMATAN : [070] CIBINGBIN

Data Kemendagri			MFD 2021 Semester 2			
No	Kode	Nama Desa	No	Kode	Nama Desa	Status*
1	32.08.05.2003	CIANGIR	1	3208070002	CIANGIR	2
2	32.08.05.2001	CIPONDOK	2	3208070003	CIPONDOK	2
3	32.08.05.2009	SUKAHARJA	3	3208070004	SUKAHARJA	1
4	32.08.05.2002	SINDANGJAWA	4	3208070005	SINDANGJAWA	1
5	32.08.05.2008	SUKAMAJU	5	3208070011	SUKAMAJU	1
6	32.08.05.2004	CIBINGBIN	6	3208070012	CIBINGBIN	1
7	32.08.05.2005	CITENJO	7	3208070013	CITENJO	1
8	32.08.05.2006	DUKUHBADAG	8	3208070014	DUKUHBADAG	2
9	32.08.05.2010	CISAAT	9	3208070017	CISAAT	2
10	32.08.05.2007	BANTARPAN-JANG	10	3208070018	BANTARPAN-JANG	2

Catatan :
*) 1. Perkotaan
2. Perdesaan

https://jabar.bps.go.id

DAFTAR DESA/KELURAHAN

PROVINSI : [32] JAWA BARAT
KAB/KOTA : [08] KUNINGAN
KECAMATAN : [071] CIBEUREUM

Data Kemendagri			MFD 2021 Semester 2			
No	Kode	Nama Desa	No	Kode	Nama Desa	Status*
1	32.08.28.2001	CIMARA	1	3208071001	CIMARA	2
2	32.08.28.2007	KAWUNGSARI	2	3208071002	KAWUNGSARI	2
3	32.08.28.2008	SUKARAPIH	3	3208071003	SUKARAPIH	2
4	32.08.28.2002	SUMURWIRU	4	3208071004	SUMURWIRU	2
5	32.08.28.2003	CIBEUREUM	5	3208071005	CIBEUREUM	2
6	32.08.28.2005	RANDUSARI	6	3208071006	RANDUSARI	2
7	32.08.28.2006	SUKADANA	7	3208071007	SUKADANA	2
8	32.08.28.2004	TARIKOLOT	8	3208071008	TARIKOLOT	2

Catatan :
*) 1. Perkotaan
2. Perdesaan

https://jabar.bps.go.id

PROVINSI : [32] JAWA BARAT
KAB/KOTA : [08] KUNINGAN
KECAMATAN : [080] LURAAGUNG

Data Kemendagri			MFD 2021 Semester 2			
No	Kode	Nama Desa	No	Kode	Nama Desa	Status*
1	32.08.06.2002	WALAHARCA-GEUR	1	3208080001	WALAHARCA-GEUR	2
2	32.08.06.2001	DUKUHPI-CUNG	2	3208080002	DUKUHPI-CUNG	2
3	32.08.06.2003	WILANAGARA	3	3208080003	WILANAGARA	2
4	32.08.06.2006	SINDANGSARI	4	3208080004	SINDANGSARI	2
5	32.08.06.2004	CIGEDANG	5	3208080005	CIGEDANG	1
6	32.08.06.2005	LURAGUNG TONGGOH	6	3208080006	LURAGUNG TONGGOH	1
7	32.08.06.2008	MARGASARI	7	3208080007	MARGASARI	1
8	32.08.06.2007	CIRAHAYU	8	3208080008	CIRAHAYU	2
9	32.08.06.2009	SINDANGSUKA	9	3208080009	SINDANGSUKA	1
10	32.08.06.2010	CIKANDANG	10	3208080010	CIKANDANG	2
11	32.08.06.2011	PANYOSOGAN	11	3208080011	PANYOSOGAN	2
12	32.08.06.2012	GUNUNG-KARUNG	12	3208080012	GUNUNG-KARUNG	2
13	32.08.06.2014	DUKUHMAJA	13	3208080013	DUKUHMAJA	1
14	32.08.06.2013	LURAGUNG LANDEUH	14	3208080014	LURAGUNG LANDEUH	1
15	32.08.06.2016	CIKADUWETAN	15	3208080015	CIKADUWETAN	2
16	32.08.06.2015	BENDA	16	3208080016	BENDA	2

Catatan :
*) 1. Perkotaan
2. Perdesaan

https://jabar.bps.go.id

DAFTAR DESA/KELURAHAN

PROVINSI : [32] JAWA BARAT
KAB/KOTA : [08] KUNINGAN
KECAMATAN : [081] CIMAHI

Data Kemendagri			MFD 2021 Semester 2			
No	Kode	Nama Desa	No	Kode	Nama Desa	Status*
1	32.08.24.2003	CILEUYA	1	3208081001	CILEUYA	2
2	32.08.24.2004	MARGAMUKTI	2	3208081004	MARGAMUKTI	2
3	32.08.24.2012	CIMULYA	3	3208081005	CIMULYA	2
4	32.08.24.2005	GUNUNGSARI	4	3208081006	GUNUNGSARI	2
5	32.08.24.2006	CIMAHI	5	3208081007	CIMAHI	2
6	32.08.24.2007	KANANGA	6	3208081008	KANANGA	2
7	32.08.24.2008	CIKEUSAL	7	3208081009	CIKEUSAL	2
8	32.08.24.2011	MULYAJAYA	8	3208081010	MULYAJAYA	2
9	32.08.24.2010	SUKAJAYA	9	3208081011	SUKAJAYA	2
10	32.08.24.2009	MEKARJAYA	10	3208081012	MEKARJAYA	2

https://jabar.bps.go.id

Catatan :
*) 1. Perkotaan
2. Perdesaan

PROVINSI : [32] JAWA BARAT
KAB/KOTA : [08] KUNINGAN
KECAMATAN : [090] CIDAHU

Data Kemendagri			MFD 2021 Semester 2			
No	Kode	Nama Desa	No	Kode	Nama Desa	Status*
1	32.08.11.2001	CIHIDEUNG GIRANG	1	3208090001	CIHIDEUNG GIRANG	1
2	32.08.11.2002	CIHIDEUNG HILIR	2	3208090002	CIHIDEUNG HILIR	1
3	32.08.11.2003	CIDAHU	3	3208090003	CIDAHU	1
4	32.08.11.2004	KERTAWINA NGUN	4	3208090004	KERTAWINA NGUN	2
5	32.08.11.2005	DATAR	5	3208090005	DATAR	2
6	32.08.11.2012	BUNDER	6	3208090006	BUNDER	2
7	32.08.11.2006	LEGOK	7	3208090007	LEGOK	2
8	32.08.11.2008	CIEURIH	8	3208090008	CIEURIH	1
9	32.08.11.2010	NANGGELA	9	3208090009	NANGGELA	2
10	32.08.11.2009	CIBULAN	10	3208090016	CIBULAN	2
11	32.08.11.2007	CIKEUSIK	11	3208090017	CIKEUSIK	2
12	32.08.11.2011	JATIMULYA	12	3208090018	JATIMULYA	2

Catatan :
*) 1. Perkotaan
2. Perdesaan

https://jabar.bps.go.id

DAFTAR DESA/KELURAHAN

PROVINSI : [32] JAWA BARAT
KAB/KOTA : [08] KUNINGAN
KECAMATAN : [091] KALIMANGGIS

Data Kemendagri			MFD 2021 Semester 2			
No	Kode	Nama Desa	No	Kode	Nama Desa	Status*
1	32.08.27.2001	KALIMANGGIS KULON	1	3208091001	KALIMANGGIS KULON	2
2	32.08.27.2006	KALIMANGGIS WETAN	2	3208091002	KALIMANGGIS WETAN	2
3	32.08.27.2003	CIPANCUR	3	3208091003	CIPANCUR	2
4	32.08.27.2002	PARTAWANGU-NAN	4	3208091004	PARTAWANGU-NAN	2
5	32.08.27.2004	KERTAWANA	5	3208091005	KERTAWANA	2
6	32.08.27.2005	WANASARAYA	6	3208091006	WANASARAYA	2

Catatan :
*) 1. Perkotaan
2. Perdesaan

https://jabar.bps.go.id

PROVINSI : [32] JAWA BARAT
KAB/KOTA : [08] KUNINGAN
KECAMATAN : [100] CIAWIGEBANG

Data Kemendagri			MFD 2021 Semester 2			
No	Kode	Nama Desa	No	Kode	Nama Desa	Status*
1	32.08.10.2024	CIJAGAMULYA	1	3208100002	CIJAGAMULYA	1
2	32.08.10.2010	CIOMAS	2	3208100003	CIOMAS	1
3	32.08.10.2007	SIDARAJA	3	3208100004	SIDARAJA	1
4	32.08.10.2006	PAJAWANLOR	4	3208100005	PAJAWANLOR	1
5	32.08.10.2004	LEBAKSIUH	5	3208100006	LEBAKSIUH	2
6	32.08.10.2017	KERAMATMULYA	6	3208100007	KERAMATMULYA	2
7	32.08.10.2001	GERESIK	7	3208100008	GERESIK	2
8	32.08.10.2005	CIPUTAT	8	3208100009	CIPUTAT	1
9	32.08.10.2008	KAPANDAYAN	9	3208100010	KAPANDAYAN	1
10	32.08.10.2022	DUKUHDALEM	10	3208100011	DUKUHDALEM	1
11	32.08.10.2009	PANGKALAN	11	3208100014	PANGKALAN	1
12	32.08.10.2003	CIAWIGEBANG	12	3208100015	CIAWIGEBANG	1
13	32.08.10.2002	KADURAMA	13	3208100016	KADURAMA	1
14	32.08.10.2018	PAMIJAHAN	14	3208100017	PAMIJAHAN	2
15	32.08.10.2019	KARANGKA MULYAN	15	3208100018	KARANGKA MULYAN	1
16	32.08.10.2013	CIAWILOR	16	3208100019	CIAWILOR	1
17	32.08.10.2012	CIHAUR	17	3208100026	CIHAUR	2
18	32.08.10.2014	CIGARUKGAK	18	3208100027	CIGARUKGAK	2
19	32.08.10.2023	MEKARJAYA	19	3208100028	MEKARJAYA	2
20	32.08.10.2011	SUKARAJA	20	3208100029	SUKARAJA	2
21	32.08.10.2020	PADARAMA	21	3208100031	PADARAMA	2
22	32.08.10.2015	SUKADANA	22	3208100032	SUKADANA	2
23	32.08.10.2021	CIKUBANGMULYA	23	3208100033	CIKUBANGMULYA	2
24	32.08.10.2016	CIHIRUP	24	3208100034	CIHIRUP	2

Catatan :
*) 1. Perkotaan
2. Perdesaan

https://jabar.bps.go.id

DAFTAR DESA/KELURAHAN

PROVINSI : [32] JAWA BARAT
KAB/KOTA : [08] KUNINGAN
KECAMATAN : [101] CIPICUNG

Data Kemendagri			MFD 2021 Semester 2			
No	Kode	Nama Desa	No	Kode	Nama Desa	Status*
1	32.08.21.2001	MUNCANGELA	1	3208101001	MUNCANGELA	2
2	32.08.21.2002	KAROYA	2	3208101002	KAROYA	1
3	32.08.21.2003	SUSUKAN	3	3208101003	SUSUKAN	2
4	32.08.21.2009	SUKAMUKTI	4	3208101004	SUKAMUKTI	2
5	32.08.21.2005	CIPICUNG	5	3208101005	CIPICUNG	2
6	32.08.21.2010	MEKARSARI	6	3208101006	MEKARSARI	2
7	32.08.21.2004	CIMARANTEN	7	3208101007	CIMARANTEN	2
8	32.08.21.2006	PAMULIHAN	8	3208101008	PAMULIHAN	2
9	32.08.21.2007	SALAREUMA	9	3208101009	SALAREUMA	2
10	32.08.21.2008	SUGANANGAN	10	3208101010	SUGANANGAN	2

https://jabar.bps.go.id

Catatan :
*) 1. Perkotaan
2. Perdesaan

PROVINSI : [32] JAWA BARAT
KAB/KOTA : [08] KUNINGAN
KECAMATAN : [110] LEBAKWANGI

Data Kemendagri			MFD 2021 Semester 2			
No	Kode	Nama Desa	No	Kode	Nama Desa	Status*
1	32.08.07.2011	CINAGARA	1	3208110014	CINAGARA	1
2	32.08.07.2012	CINEUMBEUY	2	3208110015	CINEUMBEUY	1
3	32.08.07.2013	CIPETIR	3	3208110016	CIPETIR	2
4	32.08.07.2014	LEBAKWANGI	4	3208110017	LEBAKWANGI	1
5	32.08.07.2015	MANCAGAR	5	3208110018	MANCAGAR	1
6	32.08.07.2010	LANGSEB	6	3208110019	LANGSEB	1
7	32.08.07.2019	PAJAWAN KIDUL	7	3208110023	PAJAWAN KIDUL	2
8	32.08.07.2020	PANGUNDAN	8	3208110024	PANGUNDAN	2
9	32.08.07.2025	MANGGARI	9	3208110025	MANGGARI	2
10	32.08.07.2018	PASAYANGAN	10	3208110026	PASAYANGAN	2
11	32.08.07.2017	SINDANG	11	3208110027	SINDANG	2
12	32.08.07.2016	BENDUNGAN	12	3208110028	BENDUNGAN	2
13	32.08.07.2021	MEKARWANGI	13	3208110029	MEKARWANGI	1

Catatan :
*) 1. Perkotaan
2. Perdesaan

https://jabar.bps.go.id

DAFTAR DESA/KELURAHAN

PROVINSI : [32] JAWA BARAT
KAB/KOTA : [08] KUNINGAN
KECAMATAN : [111] MALEBER

Data Kemendagri			MFD 2021 Semester 2			
No	Kode	Nama Desa	No	Kode	Nama Desa	Status*
1	32.08.30.2003	CIPAKEM	1	3208111001	CIPAKEM	2
2	32.08.30.2015	GIRIWARINGIN	2	3208111002	GIRIWARINGIN	2
3	32.08.30.2001	GARAHAJI	3	3208111003	GARAHAJI	2
4	32.08.30.2002	GALAHERANG	4	3208111004	GALAHERANG	1
5	32.08.30.2010	MEKARSARI	5	3208111005	MEKARSARI	2
6	32.08.30.2011	PADAMULYA	6	3208111006	PADAMULYA	2
7	32.08.30.2012	CIKAHURIPAN	7	3208111007	CIKAHURIPAN	2
8	32.08.30.2005	PARAKAN	8	3208111008	PARAKAN	2
9	32.08.30.2013	KUTAMANDA-RAKAN	9	3208111009	KUTAMANDA-RAKAN	1
10	32.08.30.2004	MALEBER	10	3208111010	MALEBER	1
11	32.08.30.2009	KARANG TENGAH	11	3208111011	KARANG TENGAH	1
12	32.08.30.2008	DUKUH TENGAH	12	3208111012	DUKUH TENGAH	2
13	32.08.30.2016	BUNIASIH	13	3208111013	BUNIASIH	1
14	32.08.30.2007	CIPORANG	14	3208111014	CIPORANG	1
15	32.08.30.2006	KUTARAJA	15	3208111015	KUTARAJA	1
16	32.08.30.2014	MANDALA-JAYA	16	3208111016	MANDALA-JAYA	2

Catatan :
*) 1. Perkotaan
2. Perdesaan

https://jabar.bps.go.id

PROVINSI : [32] JAWA BARAT
KAB/KOTA : [08] KUNINGAN
KECAMATAN : [120] GARAWANGI

Data Kemendagri			MFD 2021 Semester 2			
No	Kode	Nama Desa	No	Kode	Nama Desa	Status*
1	32.08.08.2002	CIRUKEM	1	3208120001	CIRUKEM	2
2	32.08.08.2001	GEWOK	2	3208120002	GEWOK	2
3	32.08.08.2028	KUTKEMBA-RAN	3	3208120003	KUTKEMBA-RAN	2
4	32.08.08.2003	PAKEMBANG AN	4	3208120004	PAKEMBANG AN	2
5	32.08.08.2029	KADATUAN	5	3208120005	KADATUAN	2
6	32.08.08.2027	TEMBONG	6	3208120006	TEMBONG	2
7	32.08.08.2011	LENGKONG	7	3208120007	LENGKONG	1
8	32.08.08.2010	PURWASARI	8	3208120008	PURWASARI	1
9	32.08.08.2007	GARAWANGI	9	3208120009	GARAWANGI	1
10	32.08.08.2023	KARAMAT-WANGI	10	3208120010	KARAMAT-WANGI	1
11	32.08.08.2004	SUKAIMUT	11	3208120011	SUKAIMUT	2
12	32.08.08.2005	CIKANANGA	12	3208120012	CIKANANGA	1
13	32.08.08.2006	TAMBAKBAYA	13	3208120013	TAMBAKBAYA	2
14	32.08.08.2026	MEKARMULYA	14	3208120014	MEKARMULYA	1
15	32.08.08.2008	SUKAMULYA	15	3208120015	SUKAMULYA	1
16	32.08.08.2009	MANCAGAR	16	3208120016	MANCAGAR	1
17	32.08.08.2024	CITIUSARI	17	3208120017	CITIUSARI	1

Catatan :
*) 1. Perkotaan
2. Perdesaan

https://jabar.bps.go.id

DAFTAR DESA/KELURAHAN

PROVINSI : [32] JAWA BARAT
KAB/KOTA : [08] KUNINGAN
KECAMATAN : [121] SINDANG AGUNG

Data Kemendagri			MFD 2021 Semester 2			
No	Kode	Nama Desa	No	Kode	Nama Desa	Status*
1	32.08.31.2003	KERTAUNGA-RAN	1	3208121001	KERTAUNGA-RAN	2
2	32.08.31.2002	KADUAGUNG	2	3208121002	KADUAGUNG	1
3	32.08.31.2001	SINDANGSARI	3	3208121003	SINDANGSARI	2
4	32.08.31.2007	KERTAWANGU-NAN	4	3208121004	KERTAWANGU-NAN	1
5	32.08.31.2004	SINDANG AGUNG	5	3208121005	SINDANG AGUNG	2
6	32.08.31.2005	BALONG	6	3208121006	BALONG	2
7	32.08.31.2012	MEKARMUKTI	7	3208121007	MEKARMUKTI	1
8	32.08.31.2006	KERTAYASA	8	3208121008	KERTAYASA	1
9	32.08.31.2009	TIRTAWANGU-NAN	9	3208121009	TIRTAWANGU-NAN	1
10	32.08.31.2008	BABAKAN REUMA	10	3208121010	BABAKAN REUMA	2
11	32.08.31.2010	DUKUH LOR	11	3208121011	DUKUH LOR	2
12	32.08.31.2011	TARAJU	12	320812102	TARAJU	2

Catatan :
*) 1. Perkotaan
2. Perdesaan

https://jabar.bps.go.id

PROVINSI : [32] JAWA BARAT
KAB/KOTA : [08] KUNINGAN
KECAMATAN : [130] KUNINGAN

Data Kemendagri			MFD 2021 Semester 2			
No	Kode	Nama Desa	No	Kode	Nama Desa	Status*
1	32.08.09.2011	CIBINUANG	1	3208130001	CIBINUANG	1
2	32.08.09.1001	CITANGTU	2	3208130002	CITANGTU	2
3	32.08.09.2012	KARANG-TAWANG	3	3208130003	KARANG-TAWANG	1
4	32.08.09.1003	WINDUHAJI	4	3208130004	WINDUHAJI	1
5	32.08.09.1002	KUNINGAN	5	3208130005	KUNINGAN	1
6	32.08.09.1006	PURWAWINA NGUN	6	3208130006	PURWAWINA NGUN	1
7	32.08.09.1007	CIGINTUNG	7	3208130007	CIGINTUNG	1
8	32.08.09.1005	CIJOHO	8	3208130008	CIJOHO	1
9	32.08.09.1004	WINDUSENG-KAHAN	9	3208130009	WINDUSENG-KAHAN	1
10	32.08.09.1009	CIPORANG	10	3208130010	CIPORANG	1
11	32.08.09.2014	ANCARAN	11	3208130011	ANCARAN	1
12	32.08.09.2013	KEDUNGARUM	12	3208130012	KEDUNGARUM	1
13	32.08.09.1008	CIRENDANG	13	3208130013	CIRENDANG	1
14	32.08.09.1010	AWIRARANGAN	14	3208130014	AWIRARANGAN	1
15	32.08.09.2015	KASTURI	15	3208130015	KASTURI	1
16	32.08.09.2016	PADAREK	16	3208130016	PADAREK	2

https://jabar.bps.go.id

Catatan :
*) 1. Perkotaan
2. Perdesaan

DAFTAR DESA/KELURAHAN

PROVINSI : [32] JAWA BARAT
KAB/KOTA : [08] KUNINGAN
KECAMATAN : [140] CIGUGUR

Data Kemendagri			MFD 2021 Semester 2			
No	Kode	Nama Desa	No	Kode	Nama Desa	Status*
1	32.08.18.1001	CIGADUNG	1	3208140001	CIGADUNG	1
2	32.08.18.1002	SUKAMULYA	2	3208140002	SUKAMULYA	1
3	32.08.18.1003	CILEULEUY	3	3208140003	CILEULEUY	1
4	32.08.18.1004	PUNCAK	4	3208140004	PUNCAK	2
5	32.08.18.1005	BABAKAN MULYA	5	3208140005	BABAKAN MULYA	2
6	32.08.18.2006	CISANTANA	6	3208140006	CISANTANA	2
7	32.08.18.2007	CIGUGUR	7	3208140007	CIGUGUR	1
8	32.08.18.2008	WINDUHERANG	8	3208140008	WINDUHERANG	1
9	32.08.18.2009	GUNUNGKE-LING	9	3208140009	GUNUNGKE-LING	1
10	32.08.18.2010	CIPARI	10	3208140010	CIPARI	1

https://jabar.bps.go.id

Catatan :
*) 1. Perkotaan
2. Perdesaan

PROVINSI : [32] JAWA BARAT
KAB/KOTA : [08] KUNINGAN
KECAMATAN : [150] KRAMATMULYA

Data Kemendagri			MFD 2021 Semester 2			
No	Kode	Nama Desa	No	Kode	Nama Desa	Status*
1	32.08.16.2010	PAJAMBON	1	3208150001	PAJAMBON	2
2	32.08.16.2009	RAGAWACANA	2	3208150002	RAGAWACANA	2
3	32.08.16.2007	CILOWA	3	3208150003	CILOWA	1
4	32.08.16.2002	GEREBA	4	3208150005	GEREBA	2
5	32.08.16.2005	CIKUBANGSARI	5	3208150007	CIKUBANGSARI	1
6	32.08.16.2017	WIDARASARI	6	3208150008	WIDARASARI	2
7	32.08.16.2004	CILAJA	7	3208150009	CILAJA	2
8	32.08.16.2006	BOJONG	8	3208150010	BOJONG	1
9	32.08.16.2014	CIKASO	9	3208150011	CIKASO	1
10	32.08.16.2013	KRAMATMU-LYA	10	3208150012	KRAMATMU-LYA	1
11	32.08.16.2008	CIBENTANG	11	3208150013	CIBENTANG	2
12	32.08.16.2011	GANDASOLI	12	3208150014	GANDASOLI	1
13	32.08.16.2012	KALAPA-GUNUNG	13	3208150015	KALAPA-GUNUNG	1
14	32.08.16.2015	KARANG MANGU	14	3208150017	KARANG MANGU	1

Catatan :
*) 1. Perkotaan
2. Perdesaan

https://jabar.bps.go.id

DAFTAR DESA/KELURAHAN

PROVINSI : [32] JAWA BARAT
KAB/KOTA : [08] KUNINGAN
KECAMATAN : [160] JALAKSANA

Data Kemendagri			MFD 2021 Semester 2			
No	Kode	Nama Desa	No	Kode	Nama Desa	Status*
1	32.08.12.2001	SUKAMUKTI	1	3208160001	SUKAMUKTI	2
2	32.08.12.2002	SIDAMULYA	2	3208160002	SIDAMULYA	2
3	32.08.12.2003	JALAKSANA	3	3208160003	JALAKSANA	1
4	32.08.12.2013	BABAKAN MULYA	4	3208160004	BABAKAN MULYA	2
5	32.08.12.2004	SANGKAN ERANG	5	3208160005	SANGKAN ERANG	2
6	32.08.12.2005	SAYANA	6	3208160006	SAYANA	2
7	32.08.12.2006	PEUSING	7	3208160007	PEUSING	2
8	32.08.12.2007	SEMBAWA	8	3208160008	SEMBAWA	2
9	32.08.12.2008	SADAMANTRA	9	3208160009	SADAMANTRA	1
10	32.08.12.2009	MANISKIDUL	10	3208160010	MANISKIDUL	1
11	32.08.12.2010	MANISLOR	11	3208160011	MANISLOR	1
12	32.08.12.2012	PADAMENAK	12	3208160013	PADAMENAK	1
13	32.08.12.2011	CINIRU	13	3208160014	CINIRU	1
14	32.08.12.2014	SINDANGBA-RANG	14	3208160016	SINDANGBA-RANG	2
15	32.08.12.2015	NANGGERANG	15	3208160017	NANGGERANG	1

Catatan :
*) 1. Perkotaan
2. Perdesaan

https://jabar.bps.go.id

PROVINSI : [32] JAWA BARAT
KAB/KOTA : [08] KUNINGAN
KECAMATAN : [161] JAPARA

Data Kemendagri			MFD 2021 Semester 2			
No	Kode	Nama Desa	No	Kode	Nama Desa	Status*
1	32.08.23.2002	RAJADANU	1	3208161001	RAJADANU	2
2	32.08.23.2010	DUKUHDALEM	2	3208161002	DUKUHDALEM	2
3	32.08.23.2001	GARATENGAH	3	3208161003	GARATENGAH	1
4	32.08.23.2004	JAPARA	4	3208161004	JAPARA	2
5	32.08.23.2003	SINGKUP	5	3208161005	SINGKUP	2
6	32.08.23.2005	WANO	6	3208161006	WANO	2
7	32.08.23.2006	CITAPEN	7	3208161007	CITAPEN	1
8	32.08.23.2007	CENGAL	8	3208161008	CENGAL	2
9	32.08.23.2008	CIKELENG	9	3208161009	CIKELENG	2
10	32.08.23.2009	KALIMATI	10	3208161010	KALIMATI	2

https://jabar.bps.go.id

Catatan :
*) 1. Perkotaan
2. Perdesaan

DAFTAR DESA/KELURAHAN

PROVINSI : [32] JAWA BARAT
KAB/KOTA : [08] KUNINGAN
KECAMATAN : [170] CILIMUS

Data Kemendagri			MFD 2021 Semester 2			
No	Kode	Nama Desa	No	Kode	Nama Desa	Status*
1	32.08.13.2007	BANDORASA KULON	1	3208170001	BANDORASA KULON	2
2	32.08.13.2006	BANDORASA WETAN	2	3208170002	BANDORASA WETAN	1
3	32.08.13.2010	BOJONG	3	3208170012	BOJONG	1
4	32.08.13.2023	LINGGAMEKAR	4	3208170013	LINGGAMEKAR	1
5	32.08.13.2008	LINGGASANA	5	3208170014	LINGGASANA	1
6	32.08.13.2009	LINGGARJATI	6	3208170015	LINGGARJATI	2
7	32.08.13.2024	LINGGAINDAH	7	3208170016	LINGGAINDAH	2
8	32.08.13.2015	CILIMUS	8	3208170017	CILIMUS	1
9	32.08.13.2020	CARACAS	9	3208170020	CARACAS	1
10	32.08.13.2019	SAMPORA	10	3208170021	SAMPORA	1
11	32.08.13.2018	KALIAREN	11	3208170022	KALIAREN	1
12	32.08.13.2016	SETIANEGARA	12	3208170023	SETIANEGARA	2
13	32.08.13.2017	CIBEUREUM	13	3208170024	CIBEUREUM	2

Catatan :
*) 1. Perkotaan
2. Perdesaan

https://jabar.bps.go.id

PROVINSI : [32] JAWA BARAT
KAB/KOTA : [08] KUNINGAN
KECAMATAN : [171] CIGANDAMEKAR

Data Kemendagri			MFD 2021 Semester 2			
No	Kode	Nama Desa	No	Kode	Nama Desa	Status*
1	32.08.32.2005	SANGKANURIP	1	3208171001	SANGKANURIP	1
2	32.08.32.2011	SANGKA MULYA	2	3208171002	SANGKA MULYA	2
3	32.08.32.2004	KARANGMUN-CANG	3	3208171003	KARANGMUN-CANG	2
4	32.08.32.2003	KOREAK	4	3208171004	KOREAK	2
5	32.08.32.2002	JAMBUGEULIS	5	3208171005	JAMBUGEULIS	2
6	32.08.32.2001	BUNIGEULIS	6	3208171006	BUNIGEULIS	2
7	32.08.32.2008	BABAKANJATI	7	3208171007	BABAKANJATI	2
8	32.08.32.2007	TIMBANG	8	3208171008	TIMBANG	1
9	32.08.32.2006	PANAWUAN	9	3208171009	PANAWUAN	1
10	32.08.32.2009	INDAPATRA	10	3208171010	INDAPATRA	1
11	32.08.32.2010	CIBUNTU	11	3208171011	CIBUNTU	2

Catatan :
*) 1. Perkotaan
2. Perdesaan

https://jabar.bps.go.id

DAFTAR DESA/KELURAHAN

PROVINSI : [32] JAWA BARAT
KAB/KOTA : [08] KUNINGAN
KECAMATAN : [180] MANDIRANCAN

Data Kemendagri			MFD 2021 Semester 2			
No	Kode	Nama Desa	No	Kode	Nama Desa	Status*
1	32.08.14.2001	TRIJAYA	1	3208180001	TRIJAYA	2
2	32.08.14.2002	RANDOBAWA GIRANG	2	3208180002	RANDOBAWA GIRANG	2
3	32.08.14.2003	SALAKADO-MAS	3	3208180003	SALAKADO-MAS	2
4	32.08.14.2004	PAKEMBANG AN	4	3208180004	PAKEMBANG AN	2
5	32.08.14.2005	RANDOBAWA ILIR	5	3208180007	RANDOBAWA ILIR	2
6	32.08.14.2006	KERTAWINANG UN	6	3208180008	KERTAWINANG UN	2
7	32.08.14.2007	SEDA	7	3208180009	SEDA	2
8	32.08.14.2008	NANGGERANG JAYA	8	3208180010	NANGGERANG JAYA	2
9	32.08.14.2009	SUKASARI	9	3208180011	SUKASARI	1
10	32.08.14.2010	CIREA	10	3208180012	CIREA	2
11	32.08.14.2011	NANGGELA	11	3208180013	NANGGELA	2
12	32.08.14.2012	MANDIRAN-CAN	12	3208180014	MANDIRAN-CAN	1

Catatan :
*) 1. Perkotaan
2. Perdesaan

https://jabar.bps.go.id

PROVINSI : [32] JAWA BARAT
KAB/KOTA : [08] KUNINGAN
KECAMATAN : [181] PANCALANG

Data Kemendagri			MFD 2021 Semester 2			
No	Kode	Nama Desa	No	Kode	Nama Desa	Status*
1	32.08.22.2001	SILEBU	1	3208181001	SILEBU	2
2	32.08.22.2003	KAHIYANG	2	3208181002	KAHIYANG	2
3	32.08.22.2002	PATALAGAN	3	3208181003	PATALAGAN	2
4	32.08.22.2006	SUMBAKELING	4	3208181004	SUMBAKELING	2
5	32.08.22.2013	DANALAMPAH	5	3208181005	DANALAMPAH	2
6	32.08.22.2008	SINDANGKEM-PENG	6	3208181006	SINDANGKEM-PENG	2
7	32.08.22.2005	PANCALANG	7	3208181007	PANCALANG	2
8	32.08.22.2004	TAJURBUNTU	8	3208181008	TAJURBUNTU	2
9	32.08.22.2009	RAJAWETAN	9	3208181009	RAJAWETAN	2
10	32.08.22.2011	MEKARJAYA	10	3208181010	MEKARJAYA	2
11	32.08.22.2010	TENJOLAYAR	11	3208181011	TENJOLAYAR	2
12	32.08.22.2012	TARIKOLOT	12	3208181012	TARIKOLOT	2
13	32.08.22.2007	SAREWU	13	3208181013	SAREWU	2

Catatan :
*) 1. Perkotaan
2. Perdesaan

https://jabar.bps.go.id

DAFTAR DESA/KELURAHAN

PROVINSI : [32] JAWA BARAT
KAB/KOTA : [08] KUNINGAN
KECAMATAN : [190] PASAWAHAN

Data Kemendagri			MFD 2021 Semester 2			
No	Kode	Nama Desa	No	Kode	Nama Desa	Status*
1	32.08.19.2008	CIBUNTU	1	3208190001	CIBUNTU	2
2	32.08.19.2007	PANIIS	2	3208190002	PANIIS	2
3	32.08.19.2009	SINGKUP	3	3208190003	SINGKUP	2
4	32.08.19.2005	CIDAHU	4	3208190004	CIDAHU	2
5	32.08.19.2003	PASAWAHAN	5	3208190005	PASAWAHAN	1
6	32.08.19.2001	PADABEUNG-HAR	6	3208190006	PADABEUNG-HAR	2
7	32.08.19.2002	KADUELA	7	3208190007	KADUELA	1
8	32.08.19.2010	PADAMATANG	8	3208190008	PADAMATANG	1
9	32.08.19.2004	CIWIRU	9	3208190009	CIWIRU	2
10	32.08.19.2006	CIMARA	10	3208190010	CIMARA	2

Catatan :
*) 1. Perkotaan
2. Perdesaan

https://jabar.bps.go.id

KABUPATEN CIREBON

https://jabar.bps.go.id

https://jabar.bps.go.id

PROVINSI : [32] JAWA BARAT
KAB/KOTA : [09] CIREBON

Data Kemendagri			MFD 2021 Semester 2		
No	Kode	Nama Kecamatan	No	Kode	Nama Kecamatan
1	32.09.01	WALED	1	3209010	WALED
2	32.09.32	PASALEMAN	2	3209011	PASALEMAN
3	32.09.02	CILEDUG	3	3209020	CILEDUG
4	32.09.33	PABUARAN	4	3209021	PABUARAN
5	32.09.03	LOSARI	5	3209030	LOSARI
6	32.09.04	PABEDILAN	6	3209031	PABEDILAN
7	32.09.05	BABAKAN	7	3209040	BABAKAN
8	32.09.30	GEBANG	8	3209041	GEBANG
9	32.09.06	KARANGSEMBUNG	9	3209050	KARANGSEMBUNG
10	32.09.34	KARANGWARENG	10	3209051	KARANGWARENG
11	32.09.07	LEMAHABANG	11	3209060	LEMAH ABANG
12	32.09.08	SUSUKAN LEBAK	12	3209061	SUSUKAN LEBAK
13	32.09.09	SEDONG	13	3209070	SEDONG
14	32.09.10	ASTANAJAPURA	14	3209080	ASTANAJAPURA
15	32.09.11	PANGENAN	15	3209081	PANGENAN
16	32.09.12	MUNDU	16	3209090	MUNDU
17	32.09.13	BEBER	17	3209100	BEBER
18	32.09.38	GREGED	18	3209101	GREGED
19	32.09.14	TALUN	19	3209111	TALUN
20	32.09.15	SUMBER	20	3209120	SUMBER
21	32.09.16	DUKUPUNTANG	21	3209121	DUKUPUNTANG
22	32.09.17	PALIMANAN	22	3209130	PALIMANAN

https://jabar.bps.go.id

DAFTAR KECAMATAN

PROVINSI : [32] JAWA BARAT
KAB/KOTA : [09] CIREBON

Data Kemendagri			MFD 2021 Semester 2		
No	Kode	Nama Kecamatan	No	Kode	Nama Kecamatan
23	32.09.18	PLUMBON	23	3209140	PLUMBON
24	32.09.31	DEPOK	24	3209141	DEPOK
25	32.09.19	WERU	25	3209150	WERU
26	32.09.36	PLERED	26	3209151	PLERED
27	32.09.35	TENGAH TANI	27	3209161	TENGAH TANI
28	32.09.20	KEDAWUNG	28	3209162	KEDAWUNG
29	32.09.21	GUNUNG JATI	29	3209171	GUNUNGJATI
30	32.09.22	KAPETAKAN	30	3209180	KAPETAKAN
31	32.09.39	SURANENGGALA	31	3209181	SURANENGGALA
32	32.09.23	KLANGENAN	32	3209190	KLANGENAN
33	32.09.40	JAMBLANG	33	3209191	JAMBLANG
34	32.09.24	ARJAWINANGUN	34	3209200	ARJAWINANGUN
35	32.09.25	PANGURAGAN	35	3209201	PANGURAGAN
36	32.09.26	CIWARINGIN	36	3209210	CIWARINGIN
37	32.09.37	GEMPOL	37	3209211	GEMPOL
38	32.09.27	SUSUKAN	38	3209220	SUSUKAN
39	32.09.28	GEGESIK	39	3209230	GEGESIK
40	32.09.29	KALIWEDI	40	3209231	KALIWEDI

https://jabar.bps.go.id

JUMLAH DESA/KELURAHAN PER KECAMATAN

PROVINSI : [32] JAWA BARAT
KAB/KOTA : [09] CIREBON

Data Kemendagri				MFD 2021 Semester 2			
No	Kode	Nama Kecamatan	Jml Desa	No	Kode	Nama Kecamatan	Jml Desa
1	32.09.01	WALED	12	1	3209010	WALED	12
2	32.09.32	PASALEMAN	7	2	3209011	PASALEMAN	7
3	32.09.02	CILEDUG	10	3	3209020	CILEDUG	10
4	32.09.33	PABUARAN	7	4	3209021	PABUARAN	7
5	32.09.03	LOSARI	10	5	3209030	LOSARI	10
6	32.09.04	PABEDILAN	13	6	3209031	PABEDILAN	13
7	32.09.05	BABAKAN	14	7	3209040	BABAKAN	14
8	32.09.30	GEBANG	13	8	3209041	GEBANG	13
9	32.09.06	KARANGSEM-BUNG	8	9	3209050	KARANGSEM-BUNG	8
10	32.09.34	KARANGWARENG	9	10	3209051	KARANGWARENG	9
11	32.09.07	LEMAHABANG	13	11	3209060	LEMAH ABANG	13
12	32.09.08	SUSUKAN LEBAK	13	12	3209061	SUSUKAN LEBAK	13
13	32.09.09	SEDONG	10	13	3209070	SEDONG	10
14	32.09.10	ASTANAJAPURA	11	14	3209080	ASTANAJAPURA	11
15	32.09.11	PANGENAN	9	15	3209081	PANGENAN	9
16	32.09.12	MUNDU	12	16	3209090	MUNDU	12
17	32.09.13	BEBER	10	17	3209100	BEBER	10
18	32.09.38	GREGED	10	18	3209101	GREGED	10
19	32.09.14	TALUN	11	19	3209111	TALUN	11
20	32.09.15	SUMBER	14	20	3209120	SUMBER	14
21	32.09.16	DUKUPUNTANG	13	21	3209121	DUKUPUNTANG	13

https://jabar.bps.go.id

JUMLAH DESA/KELURAHAN PER KECAMATAN

PROVINSI : [32] JAWA BARAT
KAB/KOTA : [09] CIREBON

Data Kemendagri				MFD 2021 Semester 2			
No	Kode	Nama Kecamatan	Jml Desa	No	Kode	Nama Kecamatan	Jml Desa
22	32.09.17	PALIMANAN	12	22	3209130	PALIMANAN	12
23	32.09.18	PLUMBON	15	23	3209140	PLUMBON	15
24	32.09.31	DEPOK	12	24	3209141	DEPOK	12
25	32.09.19	WERU	9	25	3209150	WERU	9
26	32.09.36	PLERED	10	26	3209151	PLERED	10
27	32.09.35	TENGAH TANI	8	27	3209161	TENGAH TANI	8
28	32.09.20	KEDAWUNG	8	28	3209162	KEDAWUNG	8
29	32.09.21	GUNUNG JATI	15	29	3209171	GUNUNGJATI	15
30	32.09.22	KAPETAKAN	9	30	3209180	KAPETAKAN	9
31	32.09.39	SURANENGGALA	9	31	3209181	SURANENGGALA	9
32	32.09.23	KLANGENAN	9	32	3209190	KLANGENAN	9
33	32.09.40	JAMBLANG	8	33	3209191	JAMBLANG	8
34	32.09.24	ARJAWINANGUN	11	34	3209200	ARJAWINANGUN	11
35	32.09.25	PANGURAGAN	9	35	3209201	PANGURAGAN	9
36	32.09.26	CIWARINGIN	8	36	3209210	CIWARINGIN	8
37	32.09.37	GEMPOL	8	37	3209211	GEMPOL	8
38	32.09.27	SUSUKAN	12	38	3209220	SUSUKAN	12
39	32.09.28	GEGESIK	14	39	3209230	GEGESIK	14
40	32.09.29	KALIWEDI	9	40	3209231	KALIWEDI	9

https://jabar.bps.go.id

PROVINSI : [32] JAWA BARAT
KAB/KOTA : [09] CIREBON
KECAMATAN : [010] WALED

Data Kemendagri			MFD 2021 Semester 2			
No	Kode	Nama Desa	No	Kode	Nama Desa	Status*
1	32.09.01.2008	WALED DESA	1	3209010008	WALED DESA	1
2	32.09.01.2009	WALED KOTA	2	3209010009	WALED KOTA	1
3	32.09.01.2010	MEKARSARI	3	3209010010	MEKARSARI	1
4	32.09.01.2011	WALED ASEM	4	3209010011	WALED ASEM	1
5	32.09.01.2012	AMBIT	5	3209010012	AMBIT	1
6	32.09.01.2013	CIUYAH	6	3209010013	CIUYAH	1
7	32.09.01.2014	GUNUNGSARI	7	3209010014	GUNUNGSARI	2
8	32.09.01.2015	KARANGSARI	8	3209010015	KARANGSARI	2
9	32.09.01.2016	CIKULAK KIDUL	9	3209010016	CIKULAK KIDUL	1
10	32.09.01.2017	CIKULAK	10	3209010017	CIKULAK	1
11	32.09.01.2018	CIBOGO	11	3209010018	CIBOGO	1
12	32.09.01.2019	CISAAT	12	3209010019	CISAAT	2

Catatan :
*) 1. Perkotaan
2. Perdesaan

https://jabar.bps.go.id

DAFTAR DESA/KELURAHAN

PROVINSI : [32] JAWA BARAT
KAB/KOTA : [09] CIREBON
KECAMATAN : [011] PASALEMAN

Data Kemendagri			MFD 2021 Semester 2			
No	Kode	Nama Desa	No	Kode	Nama Desa	Status*
1	32.09.32.2001	TONJONG	1	3209011001	TONJONG	2
2	32.09.32.2002	TANJUNG ANOM	2	3209011002	TANJUNG ANOM	2
3	32.09.32.2003	CILENGKRANG GIRANG	3	3209011003	CILENGKRANG GIRANG	1
4	32.09.32.2004	CILENGKRANG	4	3209011004	CILENGKRANG	1
5	32.09.32.2005	PASALEMAN	5	3209011005	PASALEMAN	1
6	32.09.32.2006	CIGOBANG WANGI	6	3209011006	CIGOBANG WANGI	1
7	32.09.32.2007	CIGOBANG	7	3209011007	CIGOBANG	2

Catatan :
*) 1. Perkotaan
2. Perdesaan

https://jabar.bps.go.id

PROVINSI : [32] JAWA BARAT
KAB/KOTA : [09] CIREBON
KECAMATAN : [020] CILEDUG

Data Kemendagri			MFD 2021 Semester 2			
No	Kode	Nama Desa	No	Kode	Nama Desa	Status*
1	32.09.02.2008	LEUWEUNG-GAJAH	1	3209020008	LEUWEUNG-GAJAH	1
2	32.09.02.2009	TENJOMAYA	2	3209020009	TENJOMAYA	1
3	32.09.02.2010	DAMARGUNA	3	3209020010	DAMARGUNA	1
4	32.09.02.2011	JATISEENG	4	3209020011	JATISEENG	1
5	32.09.02.2012	JATISEENG KIDUL	5	3209020012	JATISEENG KIDUL	1
6	32.09.02.2013	CILEDUG KULON	6	3209020013	CILEDUG KULON	1
7	32.09.02.2014	CILEDUG WETAN	7	3209020014	CILEDUG WETAN	1
8	32.09.02.2015	CILEDUG LOR	8	3209020015	CILEDUG LOR	1
9	32.09.02.2016	CILEDUG TENGAH	9	3209020016	CILEDUG TENGAH	1
10	32.09.02.2017	BOJONG NEGARA	10	3209020017	BOJONG NEGARA	1

https://jabar.bps.go.id

Catatan :
*) 1. Perkotaan
2. Perdesaan

DAFTAR DESA/KELURAHAN

PROVINSI : [32] JAWA BARAT
KAB/KOTA : [09] CIREBON
KECAMATAN : [021] PABUARAN

Data Kemendagri			MFD 2021 Semester 2			
No	Kode	Nama Desa	No	Kode	Nama Desa	Status*
1	32.09.33.2001	SUKADANA	1	3209021001	SUKADANA	1
2	32.09.33.2002	PABUARAN KIDUL	2	3209021002	PABUARAN KIDUL	1
3	32.09.33.2003	PABUARAN WETAN	3	3209021003	PABUARAN WETAN	1
4	32.09.33.2004	PABUARAN LOR	4	3209021004	PABUARAN LOR	1
5	32.09.33.2005	JATIRENGGANG	5	3209021005	JATIRENGGANG	1
6	32.09.33.2006	HULUBANTENG	6	3209021006	HULUBANTENG	1
7	32.09.33.2007	HULUBANTENG LOR	7	3209021007	HULUBANTENG LOR	1

Catatan :
*) 1. Perkotaan
2. Perdesaan

https://jabar.bps.go.id

PROVINSI : [32] JAWA BARAT
KAB/KOTA : [09] CIREBON
KECAMATAN : [030] LOSARI

Data Kemendagri			MFD 2021 Semester 2			
No	Kode	Nama Desa	No	Kode	Nama Desa	Status*
1	32.09.03.2001	ASTANA-LANGGAR	1	3209030009	ASTANA-LANGGAR	1
2	32.09.03.2002	BARISAN	2	3209030010	BARISAN	1
3	32.09.03.2003	LOSARI KIDUL	3	3209030011	LOSARI KIDUL	1
4	32.09.03.2004	PANGGANG-SARI	4	3209030012	PANGGANG-SARI	1
5	32.09.03.2005	LOSARI LOR	5	3209030013	LOSARI LOR	1
6	32.09.03.2006	MULYASARI	6	3209030014	MULYASARI	1
7	32.09.03.2007	KALIRAHAYU	7	3209030015	KALIRAHAYU	2
8	32.09.03.2008	KALISARI	8	3209030016	KALISARI	1
9	32.09.03.2009	AMBULU	9	3209030017	AMBULU	2
10	32.09.03.2010	TAWANGSARI	10	3209030018	TAWANGSARI	2

Catatan :
*) 1. Perkotaan
2. Perdesaan

https://jabar.bps.go.id

DAFTAR DESA/KELURAHAN

PROVINSI : [32] JAWA BARAT
KAB/KOTA : [09] CIREBON
KECAMATAN : [031] PABEDILAN

Data Kemendagri			MFD 2021 Semester 2			
No	Kode	Nama Desa	No	Kode	Nama Desa	Status*
1	32.09.04.2012	BABAKAN LOSARI	1	3209031001	BABAKAN LOSARI	1
2	32.09.04.2011	SIDARESMI	2	3209031002	SIDARESMI	2
3	32.09.04.2009	KALIBUNTU	3	3209031003	KALIBUNTU	2
4	32.09.04.2008	DUKUHWIDA-RA	4	3209031004	DUKUHWIDA-RA	1
5	32.09.04.2007	PASURUAN	5	3209031005	PASURUAN	1
6	32.09.04.2010	KALIMUKTI	6	3209031006	KALIMUKTI	1
7	32.09.04.2004	PABEDILAN KALER	7	3209031007	PABEDILAN KALER	1
8	32.09.04.2013	BABAKAN LOSARI LOR	8	3209031008	BABAKAN LOSARI LOR	1
9	32.09.04.2001	PABEDILAN KIDUL	9	3209031009	PABEDILAN KIDUL	1
10	32.09.04.2003	PABEDILAN KULON	10	3209031010	PABEDILAN KULON	1
11	32.09.04.2002	PABEDILAN WETAN	11	3209031011	PABEDILAN WETAN	1
12	32.09.04.2006	TERSANA	12	3209031012	TERSANA	1
13	32.09.04.2005	SILIHASIH	13	3209031013	SILIH ASIH	1

Catatan :
*) 1. Perkotaan
2. Perdesaan

https://jabar.bps.go.id

PROVINSI : [32] JAWA BARAT
KAB/KOTA : [09] CIREBON
KECAMATAN : [040] BABAKAN

Data Kemendagri			MFD 2021 Semester 2			
No	Kode	Nama Desa	No	Kode	Nama Desa	Status*
1	32.09.04.2001	CANGKUANG	1	3209040001	CANGKUANG	1
2	32.09.04.2002	SERANG WETAN	2	3209040002	SERANG WETAN	1
3	32.09.04.2008	BOJONGGE-BANG	3	3209040003	BOJONGGE-BANG	1
4	32.09.04.2012	KUDUKERAS	4	3209040004	KUDUKERAS	1
5	32.09.04.2009	SUMBER KIDUL	5	3209040005	SUMBER KIDUL	1
6	32.09.04.2011	KUDUMULYA	6	3209040006	KUDUMULYA	1
7	32.09.04.2010	SUMBER LOR	7	3209040007	SUMBER LOR	2
8	32.09.04.2007	BABAKAN	8	3209040008	BABAKAN	1
9	32.09.04.2013	PAKUSAMBEN	9	3209040009	PAKUSAMBEN	1
10	32.09.04.2014	KARANGWAN-GUN	10	3209040010	KARANGWAN-GUN	1
11	32.09.04.2006	BABAKAN GEBANG	11	3209040011	BABAKAN GEBANG	1
12	32.09.04.2005	GEMBONGAN	12	3209040012	GEMBONGAN	1
13	32.09.04.2003	SERANG KU-LON	13	3209040013	SERANG KU-LON	1
14	32.09.04.2004	GEMBONGAN MEKAR	14	3209040014	GEMBONGAN MEKAR	1

Catatan :
*) 1. Perkotaan
2. Perdesaan

https://jabar.bps.go.id

DAFTAR DESA/KELURAHAN

PROVINSI : [32] JAWA BARAT
KAB/KOTA : [09] CIREBON
KECAMATAN : [041] GEBANG

Data Kemendagri			MFD 2021 Semester 2			
No	Kode	Nama Desa	No	Kode	Nama Desa	Status*
1	32.09.30.2001	DOMPYONG KULON	1	3209041001	DOMPYONG KULON	2
2	32.09.30.2002	DOMPYONG WETAN	2	3209041002	DOMPYONG WETAN	1
3	32.09.30.2003	KALIMEKAR	3	3209041003	KALIMEKAR	2
4	32.09.30.2004	KALIMORO	4	3209041004	KALIMORO	2
5	32.09.30.2005	GAGASARI	5	3209041005	GAGASARI	2
6	32.09.30.2006	KALIPASUNG	6	3209041006	KALIPASUNG	1
7	32.09.30.2007	GEBANG KU-LON	7	3209041007	GEBANG KU-LON	1
8	32.09.30.2008	GEBANG	8	3209041008	GEBANG	1
9	32.09.30.2010	GEBANG UDIK	9	3209041009	GEBANG UDIK	2
10	32.09.30.2009	GEBANG ILIR	10	3209041010	GEBANG ILIR	1
11	32.09.30.2011	GEBANG ME-KAR	11	3209041011	GEBANG ME-KAR	1
12	32.09.30.2012	PELAYANGAN	12	3209041012	PELAYANGAN	2
13	32.09.30.2013	MELAKASARI	13	3209041013	MELAKASARI	2

Catatan :
*) 1. Perkotaan
2. Perdesaan

https://jabar.bps.go.id

PROVINSI : [32] JAWA BARAT
KAB/KOTA : [09] CIREBON
KECAMATAN : [050] KARANGSEMBUNG

Data Kemendagri			MFD 2021 Semester 2			
No	Kode	Nama Desa	No	Kode	Nama Desa	Status*
1	32.09.06.2001	TAMBELANG	1	3209050008	TAMBELANG	1
2	32.09.06.2002	KARANGSU-WUNG	2	3209050015	KARANGSU-WUNG	1
3	32.09.06.2003	KARANG TENGAH	3	3209050016	KARANG TENGAH	1
4	32.09.06.2004	KALIMEANG	4	3209050017	KALIMEANG	1
5	32.09.06.2005	KARANG MALANG	5	3209050018	KARANG MALANG	1
6	32.09.06.2006	KARANG MEKAR	6	3209050019	KARANG MEKAR	1
7	32.09.06.2007	KUBANGKA-RANG	7	3209050020	KUBANGKA-RANG	1
8	32.09.06.2008	KARANGSEM-BUNG	8	3209050020	KARANGSEM-BUNG	1

https://jabar.bps.go.id

Catatan :
*) 1. Perkotaan
2. Perdesaan

DAFTAR DESA/KELURAHAN

PROVINSI : [32] JAWA BARAT
KAB/KOTA : [09] CIREBON
KECAMATAN : [051] KARANGWARENG

Data Kemendagri			MFD 2021 Semester 2			
No	Kode	Nama Desa	No	Kode	Nama Desa	Status*
1	32.09.34.2001	SEUSEUPAN	1	3209051001	SEUSEUPAN	2
2	32.09.34.2002	SUMURKON-DANG	2	3209051002	SUMURKON-DANG	2
3	32.09.34.2003	JATIPIRING	3	3209051003	JATIPIRING	1
4	32.09.34.2004	KUBANGDELEG	4	3209051004	KUBANGDELEG	1
5	32.09.34.2005	KARANGANYAR	5	3209051005	KARANGANYAR	1
6	32.09.34.2006	KARANG WANGI	6	3209051006	KARANG WANGI	1
7	32.09.34.2007	BLENDER	7	3209051007	BLENDER	1
8	32.09.34.2008	KARANG-WARENG	8	3209051008	KARANG-WARENG	1
9	32.09.34.2009	KARANGASEM	9	3209051009	KARANGASEM	1

Catatan :
*) 1. Perkotaan
2. Perdesaan

https://jabar.bps.go.id

PROVINSI : [32] JAWA BARAT
KAB/KOTA : [09] CIREBON
KECAMATAN : [060] LEMAH ABANG

Data Kemendagri			MFD 2021 Semester 2			
No	Kode	Nama Desa	No	Kode	Nama Desa	Status*
1	32.09.08.2001	PICUNGPUGUR	1	3209060005	PICUNGPUGUR	1
2	32.09.08.2002	LEUWIDING-DING	2	3209060006	LEUWIDING-DING	1
3	32.09.08.2003	ASEM	3	3209060007	ASEM	1
4	32.09.08.2004	CIPEUJEUH KULON	4	3209060013	CIPEUJEUH KULON	1
5	32.09.08.2005	SINDANG LAUT	5	3209060014	SINDANG LAUT	1
6	32.09.08.2006	CIPEUJEUH WETAN	6	3209060015	CIPEUJEUH WETAN	1
7	32.09.08.2007	LEMAHABANG KULON	7	3209060016	LEMAHABANG KULON	1
8	32.09.08.2008	LEMAHABANG	8	3209060017	LEMAHABANG	1
9	32.09.08.2009	SIGONG	9	3209060018	SIGONG	1
10	32.09.08.2010	SARAJAYA	10	3209060019	SARAJAYA	1
11	32.09.08.2011	TUK KARANG-SUWUNG	11	3209060020	TUK KARANG-SUWUNG	1
12	32.09.08.2012	BELAWA	12	3209060021	BELAWA	2
13	32.09.08.20	WANGKELANG	13	3209060022	WANGKELANG	1

Catatan :
*) 1. Perkotaan
2. Perdesaan

https://jabar.bps.go.id

DAFTAR DESA/KELURAHAN

PROVINSI : [32] JAWA BARAT
KAB/KOTA : [09] CIREBON
KECAMATAN : [061] SUSUKAN LEBAK

Data Kemendagri			MFD 2021 Semester 2			
No	Kode	Nama Desa	No	Kode	Nama Desa	Status*
1	32.09.08.2001	KARANG MANGU	1	3209061001	KARANG MANGU	2
2	32.09.08.2013	KALIGAWE	2	3209061002	KALIGAWE	1
3	32.09.08.2012	KALIGAWE WETAN	3	3209061003	KALIGAWE WETAN	1
4	32.09.08.2011	CURUG WETAN	4	3209061004	CURUG WETAN	1
5	32.09.08.2010	CURUG	5	3209061005	CURUG	1
6	32.09.08.2005	WILULANG	6	3209061006	WILULANG	1
7	32.09.08.2003	SUSUKAN AGUNG	7	3209061007	SUSUKAN AGUNG	1
8	32.09.08.2002	SUSUKAN LEBAK	8	3209061008	SUSUKAN LEBAK	2
9	32.09.08.2004	SUSUKAN TONGGOH	9	3209061009	SUSUKAN TONGGOH	1
10	32.09.08.2006	SAMPIH	10	32090610010	SAMPIH	1
11	32.09.08.2007	PASAWAHAN	11	32090610011	PASAWAHAN	1
12	32.09.08.2008	CIAWIASIH	12	32090610012	CIAWI ASIH	1
13	32.09.08.2009	CIAWIJAPURA	13	32090610013	CIAWIJAPURA	1

Catatan :
*) 1. Perkotaan
2. Perdesaan

https://jabar.bps.go.id

PROVINSI : [32] JAWA BARAT
KAB/KOTA : [09] CIREBON
KECAMATAN : [070] SEDONG

Data Kemendagri			MFD 2021 Semester 2			
No	Kode	Nama Desa	No	Kode	Nama Desa	Status*
1	32.09.09.2001	KARANGWUNI	1	3209070001	KARANGWUNI	1
2	32.09.09.2002	SEDONG KIDUL	2	3209070002	SEDONG KIDUL	1
3	32.09.09.2003	SEDOG LOR	3	3209070003	SEDOG LOR	1
4	32.09.09.2004	WINDUJAYA	4	3209070004	WINDUJAYA	2
5	32.09.09.2006	WINDUHAJI	5	3209070005	WINDUHAJI	2
6	32.09.09.2007	KERTAWANG UN	6	3209070006	KERTAWANG UN	2
7	32.09.09.2008	PENAMBANG AN	7	3209070007	PANAMBANG AN	1
8	32.09.09.2009	PUTAT	8	3209070008	PUTAT	1
9	32.09.09.2010	PANONGAN	10	3209070009	PANONGAN	1
10	32.09.09.2011	PANONGAN LOR	11	3209070009	PANONGAN LOR	2

Catatan :
*) 1. Perkotaan
2. Perdesaan

https://jabar.bps.go.id

DAFTAR DESA/KELURAHAN

PROVINSI : [32] JAWA BARAT
KAB/KOTA : [09] CIREBON
KECAMATAN : [080] ASTANAJAPURA

Data Kemendagri			MFD 2021 Semester 2			
No	Kode	Nama Desa	No	Kode	Nama Desa	Status*
1	32.09.08.2004	MUNJUL	1	3209080004	MUNJUL	2
2	32.09.10.2005	SIDAMULYA	2	3209080005	SIDAMULYA	1
3	32.09.10.2006	MERTAPADA KULON	3	3209080006	MERTAPADA KULON	1
4	32.09.10.2007	MERTAPADA WETAN	4	3209080007	MERTAPADA WETAN	1
5	32.09.10.2008	BUNTET	5	3209080008	BUNTET	1
6	32.09.10.2009	KANCI KULON	6	3209080009	KANCI KULON	2
7	32.09.10.2010	KANCI	7	3209080010	KANCI	1
8	32.09.10.2011	ASTANAJAPU-RA	8	3209080011	ASTANAJAPU-RA	1
9	32.09.10.2012	KENDAL	9	3209080015	KENDAL	1
10	32.09.10.2013	JAPURA KIDUL	10	3209080016	JAPURA KIDUL	1
11	32.09.10.2014	JAPURABAKTI	11	3209080017	JAPURABAKTI	1

Catatan :
*) 1. Perkotaan
2. Perdesaan

https://jabar.bps.go.id

PROVINSI : [32] JAWA BARAT
KAB/KOTA : [09] CIREBON
KECAMATAN : [081] PANGENAN

Data Kemendagri			MFD 2021 Semester 2			
No	Kode	Nama Desa	No	Kode	Nama Desa	Status*
1	32.09.12.2001	ASTANA MUKTI	1	3209090001	ASTANAMUKTI	2
2	32.09.12.2002	PENGARENG AN	2	3209090002	PENGARENG AN	2
3	32.09.12.2003	JAPURA LOR	3	3209090003	JAPURA LOR	1
4	32.09.12.2004	BERINGIN	4	3209090004	BERINGIN	1
5	32.09.12.2005	RAWAURIP	5	3209090005	RAWAURIP	2
6	32.09.12.2006	BENDUNGAN	6	3209090006	BENDUNGAN	2
7	32.09.12.2007	PANGENAN	7	3209090007	PANGENAN	2
8	32.09.12.2008	GETRAKMO YAN	8	3209090008	GETRAKMO YAN	2
9	32.09.12.2009	ENDER	9	3209090009	ENDER	1

Catatan :
*) 1. Perkotaan
2. Perdesaan

https://jabar.bps.go.id

DAFTAR DESA/KELURAHAN

PROVINSI : [32] JAWA BARAT
KAB/KOTA : [09] CIREBON
KECAMATAN : [090] MUNDU

Data Kemendagri			MFD 2021 Semester 2			
No	Kode	Nama Desa	No	Kode	Nama Desa	Status*
1	32.09.12.2001	SETUPATOK	1	3209090001	SETUPATOK	1
2	32.09.12.2002	PENPEN	2	3209090002	PENPEN	1
3	32.09.12.2003	MUNDUME-SIGIT	3	3209090003	MUNDU ME-SIGIT	2
4	32.09.12.2004	LUWUNG	4	3209090004	LUWUNG	1
5	32.09.12.2005	WARUDUWUR	5	3209090005	WARUDUWUR	2
6	32.09.12.2006	CITEMU	6	3209090006	CITEMU	1
7	32.09.12.2007	BANDENGAN	7	3209090007	BANDENGAN	1
8	32.09.12.2008	MUNDUPE-SISIR	8	3209090008	MUNDU PE-SISIR	1
9	32.09.12.2009	SUCI	9	3209090009	SUCI	1
10	32.09.12.2010	BANJARWANG UNAN	10	3209090010	BANJARWANG UNAN	1
11	32.09.12.2011	PAMENGKANG	11	3209090011	PAMENGKANG	1
12	32.09.12.2012	SINAR RAN-CANG	12	3209090012	SINARANCANG	1

Catatan :
*) 1. Perkotaan
2. Perdesaan

https://jabar.bps.go.id

PROVINSI : [32] JAWA BARAT
KAB/KOTA : [09] CIREBON
KECAMATAN : [100] BEBER

Data Kemendagri			MFD 2021 Semester 2			
No	Kode	Nama Desa	No	Kode	Nama Desa	Status*
1	32.09.13.2001	WANAYASA	1	3209100001	WANAYASA	1
2	32.09.13.2002	SINDANG-KASIH	2	3209100002	SINDANG-KASIH	1
3	32.09.13.2003	SINDANGHAYU	3	3209100003	SINDANGHAYU	1
4	32.09.13.2004	CIAWIGAJAH	4	3209100004	CIAWIGAJAH	1
5	32.09.13.2008	CIKANCAS	5	3209100005	CIKANCAS	1
6	32.09.13.2009	HALIMPU	6	3209100006	HALIMPU	1
7	32.09.13.2010	CIPINANG	7	3209100007	CIPINANG	1
8	32.09.13.2011	BEBER	8	3209100008	BEBER	1
9	32.09.13.2012	PATAPAN	9	3209100009	PATAPAN	1
10	32.09.13.2013	KONDANGSARI	10	32091000010	KONDANGSARI	1

Catatan :
*) 1. Perkotaan
2. Perdesaan

https://jabar.bps.go.id

DAFTAR DESA/KELURAHAN

PROVINSI : [32] JAWA BARAT
KAB/KOTA : [09] CIREBON
KECAMATAN : [101] GREGED

Data Kemendagri			MFD 2021 Semester 2			
No	Kode	Nama Desa	No	Kode	Nama Desa	Status*
1	32.09.38.2001	GUMULUNG LEBAK	1	3209101001	GUMULUNG LEBAK	2
2	32.09.38.2002	LEBAKMEKAR	2	3209101002	LEBAK MEKAR	2
3	32.09.38.2003	GUMULUNG TONGGOH	3	3209101003	GUMULUNG TONGGOH	2
4	32.09.38.2004	KAMARANG	4	3209101005	KAMARANG	2
5	32.09.38.2005	GREGED	5	3209101006	GREGED	2
6	32.09.38.2006	KAMARANG LEBAK	6	3209101007	KAMARANG LEBAK	2
7	32.09.38.2007	DURAJAYA	7	3209101014	DURAJAYA	2
8	32.09.38.2008	JATIPANCUR	8	3209101015	JATIPANCUR	2
9	32.09.38.2009	SINDANG KEM-PENG	9	3209101016	SINDANG KEM-PENG	2
10	32.09.38.2010	NANGGELA	10	3209101017	NANGGELA	2

Catatan :
*) 1. Perkotaan
2. Perdesaan

https://jabar.bps.go.id

PROVINSI : [32] JAWA BARAT
KAB/KOTA : [09] CIREBON
KECAMATAN : [111] TALUN

Data Kemendagri			MFD 2021 Semester 2			
No	Kode	Nama Desa	No	Kode	Nama Desa	Status*
1	32.09.14.2001	SAMPIRAN	1	3209111001	SAMPIRAN	1
2	32.09.14.2002	CIPERNA	2	3209111002	CIPERNA	1
3	32.09.14.2003	KECOMBERAN	3	3209111003	KECOMBERAN	1
4	32.09.14.2004	CIREBON GIRANG	4	3209111004	CIREBON GIRANG	1
5	32.09.14.2005	KERANDON	5	3209111005	KERANDON	1
6	32.09.14.2006	WANASABA KIDUL	6	3209111006	WANASABA KIDUL	1
7	32.09.14.2007	WANASABA LOR	7	3209111007	WANASABA LOR	1
8	32.09.14.2008	CEMPAKA	8	3209111012	CEMPAKA	1
9	32.09.14.2009	KEPONGPONGAN	9	3209111013	KEPONGPONGAN	1
10	32.09.14.2011	KUBANG	10	3209111014	KUBANG	2
11	32.09.14.2010	SARWADADI	11	3200111015	SARWADADI	2

Catatan :
*) 1. Perkotaan
2. Perdesaan

https://jabar.bps.go.id

DAFTAR DESA/KELURAHAN

PROVINSI : [32] JAWA BARAT
KAB/KOTA : [09] CIREBON
KECAMATAN : [120] SUMBER

Data Kemendagri			MFD 2021 Semester 2			
No	Kode	Nama Desa	No	Kode	Nama Desa	Status*
1	32.09.15.2001	MATANGAJI	1	3209120010	MATANGAJI	1
2	32.09.15.2002	SIDAWANGI	2	3209120011	SIDAWANGI	2
3	32.09.15.1003	BABAKAN	3	3209120014	BABAKAN	1
4	32.09.15.1004	SUMBER	4	3209120015	SUMBER	1
5	32.09.15.1005	PERBUTULAN	5	3209120016	PERBUTULAN	1
6	32.09.15.1006	KEMANTREN	6	3209120017	KEMANTREN	1
7	32.09.15.1007	SENDANG	7	3209120018	SENDANG	1
8	32.09.15.1008	GEGUNUNG	8	3209120019	GEGUNUNG	1
9	32.09.15.1009	PEJAMBON	9	3209120020	PEJAMBON	2
10	32.09.15.1010	WATUBELAH	10	3209120021	WATUBELAH	1
11	32.09.15.1011	PASALAKAN	11	3209120022	PASALAKAN	1
12	32.09.15.1012	KALIWADAS	12	3209120023	KALIWADAS	1
13	32.09.15.1013	TUKMUDAL	13	3209120024	TUKMUDAL	1
14	32.09.15.1014	KENANGA	14	3209120025	KENANGA	1

Catatan :
*) 1. Perkotaan
2. Perdesaan

https://jabar.bps.go.id

PROVINSI : [32] JAWA BARAT
KAB/KOTA : [09] CIREBON
KECAMATAN : [121] DUKU PUNTANG

Data Kemendagri			MFD 2021 Semester 2			
No	Kode	Nama Desa	No	Kode	Nama Desa	Status*
1	32.09.16.2001	BOBOS	1	3209121001	BOBOS	1
2	32.09.16.2002	CIKALAHANG	2	3209121002	CIKALAHANG	1
3	32.09.16.2003	MANDALA	3	3209121003	MANDALA	2
4	32.09.16.2004	CISAAT	4	3209121004	CISAAT	2
5	32.09.16.2005	SINDANGJAWA	5	3209121005	SINDANGJAWA	2
6	32.09.16.2006	SINDANG MEKAR	6	3209121006	SINDANG MEKAR	1
7	32.09.16.2007	CANGKOAK	7	3209121007	CANGKOAK	1
8	32.09.16.2008	KEPUNDUAN	8	3209121008	KEPUNDUAN	1
9	32.09.16.2009	BALAD	9	3209121009	BALAD	1
10	32.09.16.2010	DUKUPUN-TANG	10	3209121010	DUKUPUN-TANG	1
11	32.09.16.2011	CIPANAS	11	3209121011	CIPANAS	2
12	32.09.16.2012	GIRINATA	12	3209121012	GIRINATA	1
13	32.09.16.2013	KEDONGDONG KIDUL	13	3209121013	KEDONGDONG KIDUL	2

Catatan :
*) 1. Perkotaan
2. Perdesaan

https://jabar.bps.go.id

DAFTAR DESA/KELURAHAN

PROVINSI : [32] JAWA BARAT
KAB/KOTA : [09] CIREBON
KECAMATAN : [130] PALIMANAN

Data Kemendagri			MFD 2021 Semester 2			
No	Kode	Nama Desa	No	Kode	Nama Desa	Status*
1	32.09.17.2003	KEPUH	1	3209130003	KEPUH	1
2	32.09.17.2002	CILUKRAK	2	3209130006	CILUKRAK	1
3	32.09.17.2004	BALERANTE	3	3209130007	BALERANTE	1
4	32.09.17.2005	PANONGAN	4	3209130008	PANONGAN	1
5	32.09.17.2006	BEBERAN	5	3209130009	BEBERAN	1
6	32.09.17.2007	SEMPLO	6	3209130010	SEMPLO	1
7	32.09.17.2008	PALIMANAN TIMUR	7	3209130011	PALIMANAN TIMUR	1
8	32.09.17.2011	PEGAGAN	8	3209130014	PEGAGAN	1
9	32.09.17.2012	LUNGBENDA	9	3209130015	LUNGBENDA	1
10	32.09.17.2013	CIAWI	10	3209130016	CIAWI	1
11	32.09.17.2014	CENGKUANG	11	3209130017	CENGKUANG	2
12	32.09.17.2014	TEGALKARANG	12	320910018	TEGALKARANG	1

Catatan :
*) 1. Perkotaan
2. Perdesaan

https://jabar.bps.go.id

PROVINSI : [32] JAWA BARAT
KAB/KOTA : [09] CIREBON
KECAMATAN : [140] PLUMBON

Data Kemendagri			MFD 2021 Semester 2			
No	Kode	Nama Desa	No	Kode	Nama Desa	Status*
1	32.09.18.2001	CEMPAKA	1	3209140006	CEMPAKA	1
2	32.09.18.2002	PAMIJAHAN	2	3209120007	PAMIJAHAN	1
3	32.09.18.2003	LURAH	3	3209140017	LURAH	1
4	32.09.18.2004	MARIKANGEN	4	3209140018	MARIKANGEN	1
5	32.09.18.2005	BODE LOR	5	3209150019	BODE LOR	1
6	32.09.18.2006	BODESARI	6	3209140020	BODESARI	1
7	32.09.18.2007	GOMBANG	7	3209140021	GOMBANG	1
8	32.09.18.2008	KARANG MULYA	8	3209140022	KARANG MULYA	1
9	32.09.18.2009	KARANGASEM	9	3209140023	KARANGASEM	1
10	32.09.18.2010	PLUMBON	10	3209140024	PLUMBON	1
11	32.09.18.2011	PURBAWINA NGUN	11	3209140025	PURBAWINA NGUN	1
12	32.09.18.2012	KEBAREPAN	12	3209140026	KEBAREPAN	1
13	32.09.18.2013	PASANGGRA-HAN	13	3209140027	PASANGGRA-HAN	1
14	32.09.18.2014	KEDUNGSANA	14	3209140028	KEDUNGSANA	1
15	32.09.18.2015	DANAMULYA	15	3209140029	DANAMULYA	2

Catatan :
*) 1. Perkotaan
2. Perdesaan

https://jabar.bps.go.id

DAFTAR DESA/KELURAHAN

PROVINSI : [32] JAWA BARAT
KAB/KOTA : [09] CIREBON
KECAMATAN : [141] DEPOK

Data Kemendagri			MFD 2021 Semester 2			
No	Kode	Nama Desa	No	Kode	Nama Desa	Status*
1	32.09.31.2001	CIIKEDUK	1	3209141001	CIIKEDUK	1
2	32.09.31.2004	WARUGEDE	2	3209141002	WARUGEDE	1
3	32.09.31.2012	KARANG WANGI	3	3209141003	KARANG WANGI	1
4	32.09.31.2011	GETASAN	4	3209141004	GETASAN	1
5	32.09.31.2010	KEJUDEN	5	3209141005	KEJUDEN	1
6	32.09.31.2009	KEDUANAN	6	3209141006	KEDUANAN	1
7	32.09.31.2005	WARUROYOM	7	3209141007	WARUROYOM	1
8	32.09.31.2003	WARUKAWUNG	8	3209141008	WARUKAWUNG	1
9	32.09.31.2002	WARUJAYA	9	3209141009	WARUJAYA	1
10	32.09.31.2006	DEPOK	10	3209141010	DEPOK	1
11	32.09.31.2008	KASUGENGAN KIDUL	11	3209141011	KASUGENGAN KIDUL	1
12	32.09.31.2008	KASUGENGAN LOR	12	3209141012	KASUGENGAN LOR	1

Catatan :
*) 1. Perkotaan
2. Perdesaan

https://jabar.bps.go.id

PROVINSI : [32] JAWA BARAT
KAB/KOTA : [09] CIREBON
KECAMATAN : [150] WERU

Data Kemendagri			MFD 2021 Semester 2			
No	Kode	Nama Desa	No	Kode	Nama Desa	Status*
1	32.09.19.2001	KARANGSARI	1	3209150005	KARANGSARI	1
2	32.09.19.2002	KERTASARI	2	3209150006	KERTASARI	1
3	32.09.19.2004	MEGU CILIK	3	3209150007	MEGU CILIK	1
4	32.09.19.2003	MEGU GEDE	4	3209150008	MEGU GEDE	1
5	32.09.19.2005	SETU WETAN	5	3209150009	SETU WETAN	1
6	32.09.19.2007	WERU KIDUL	6	3209150010	WERU KIDUL	1
7	32.09.19.2006	SETU KULON	7	3209150011	SETU KULON	1
8	32.09.19.2009	TEGAL WANGI	8	3209150012	TEGAL WANGI	1
9	32.09.19.2008	WERU LOR	9	3209150015	WERU LOR	1

Catatan :
*) 1. Perkotaan
2. Perdesaan

https://jabar.bps.go.id

DAFTAR DESA/KELURAHAN

PROVINSI : [32] JAWA BARAT
KAB/KOTA : [09] CIREBON
KECAMATAN : [151] PLERED

Data Kemendagri			MFD 2021 Semester 2			
No	Kode	Nama Desa	No	Kode	Nama Desa	Status*
1	32.09.36.2003	PANEMBAHAN	1	3209151001	PANEMBAHAN	1
2	32.09.36.2004	TRUSMI WETAN	2	3209151002	TRUSMI WETAN	1
3	32.09.36.2005	TRUSMI KULON	3	3209151003	TRUSMI KULON	1
4	32.09.36.2008	SARABAU	4	3209151004	SARABAU	1
5	32.09.36.2007	GAMEL	5	3209151005	GAMEL	1
6	32.09.36.2006	WOTGALI	6	3209151006	WOTGALI	1
7	32.09.36.2002	KALIWULU	7	3209151007	KALIWULU	1
8	32.09.36.2001	TEGALSARI	8	3209151008	TEGALSARI	1
9	32.09.36.2009	CANGKRING	9	3209151009	CANGKRING	2
10	32.09.36.2010	PANGKALAN	10	3209151010	PANGKALAN	2

Catatan :
*) 1. Perkotaan
2. Perdesaan

https://jabar.bps.go.id

PROVINSI : [32] JAWA BARAT
KAB/KOTA : [09] CIREBON
KECAMATAN : [161] TENGAH TANI

Data Kemendagri			MFD 2021 Semester 2			
No	Kode	Nama Desa	No	Kode	Nama Desa	Status*
1	32.09.35.2001	PALIR	1	3209161001	PALIR	1
2	32.09.35.2002	ASTAPADA	2	3209161002	ASTAPADA	1
3	32.09.35.2003	GESIK	3	3209161003	GESIK	1
4	32.09.35.2004	KEMLAKAGEDE	4	3209161004	KEMLAKAGEDE	1
5	32.09.35.2005	DAWUAN	5	3209161005	DAWUAN	1
6	32.09.35.2006	BATEMBAT	6	3209161006	BATEMBAT	1
7	32.09.35.2007	KALIBARU	7	3209161007	KALIBARU	1
8	32.09.35.2008	KALITENGAH	8	3209161008	KALITENGAH	1

Catatan :
*) 1. Perkotaan
2. Perdesaan

https://jabar.bps.go.id

DAFTAR DESA/KELURAHAN

PROVINSI : [32] JAWA BARAT
KAB/KOTA : [09] CIREBON
KECAMATAN : [162] KEDAWUNG

Data Kemendagri			MFD 2021 Semester 2			
No	Kode	Nama Desa	No	Kode	Nama Desa	Status*
1	32.09.20.2005	KALIKOA	1	3209162001	KALIKOA	1
2	32.09.20.2004	KEDUNGDAWA	2	3209162002	KEDUNGDAWA	1
3	32.09.20.2006	TUK	3	3209162003	TUK	1
4	32.09.20.2007	KEDUNGJAYA	4	3209162004	KEDUNGJAYA	1
5	32.09.20.2008	KEDAWUNG	5	3209162005	KEDAWUNG	1
6	32.09.20.2009	KERTAWI NANGUN	6	3209162006	KERTAWI NANGUN	1
7	32.09.20.2010	SUTAWINANG UN	7	3209162007	SUTAWINANG UN	1
8	32.09.20.2011	PILANGSARI	8	3209162008	PILANGSARI	1

Catatan :
*) 1. Perkotaan
2. Perdesaan

https://jabar.bps.go.id

PROVINSI : [32] JAWA BARAT
KAB/KOTA : [09] CIREBON
KECAMATAN : [171] GUNUNG JATI

Data Kemendagri			MFD 2021 Semester 2			
No	Kode	Nama Desa	No	Kode	Nama Desa	Status*
1	32.09.21.2001	ADI DHARMA	1	3209171001	ADI DHARMA	1
2	32.09.21.2002	PASINDANGAN	2	3209171002	PASINDANGAN	1
3	32.09.21.2003	JADIMULYA	3	3209171003	JADIMULYA	1
4	32.09.21.2004	KLAYAN	4	3209171004	KLAYAN	1
5	32.09.21.2005	JATIMERTA	5	3209171005	JATIMERTA	1
6	32.09.21.2006	ASTANA	6	3209171006	ASTANA	1
7	32.09.21.2007	KALISAPU	7	3209171007	KALISAPU	1
8	32.09.21.2008	WANAKAYA	8	3209171008	WANAKAYA	1
9	32.09.21.2009	GROGOL	9	3209171009	GROGOL	1
10	32.09.21.2010	BABADAN	10	3209171010	BABADAN	1
11	32.09.21.2011	BUYUT	11	3209171011	BUYUT	1
12	32.09.21.2012	MAYUNG	12	3209171012	MAYUNG	1
13	32.09.39.2001	SAMBENG	13	3209171013	SAMBENG	1
14	32.09.39.2002	SIRNABAYA	14	3209171014	SIRNABAYA	1
15	32.09.21.2015	MERTASINGA	15	3209171015	MERTASINGA	1

Catatan :
*) 1. Perkotaan
2. Perdesaan

https://jabar.bps.go.id

DAFTAR DESA/KELURAHAN

PROVINSI : [32] JAWA BARAT
KAB/KOTA : [09] CIREBON
KECAMATAN : [180] KAPETAKAN

Data Kemendagri			MFD 2021 Semester 2			
No	Kode	Nama Desa	No	Kode	Nama Desa	Status*
1	32.09.22.2010	BUNGKO	1	3209180010	BUNGKO	2
2	32.09.22.2011	KERTASURA	2	3209180011	KERTASURA	2
3	32.09.22.2012	PEGAGAN KIDUL	3	3209180012	PEGAGAN KIDUL	2
4	32.09.22.2013	PEGAGAN LOR	4	3209180015	PEGAGAN LOR	1
5	32.09.22.2014	DUKUH	5	3209180016	DUKUH	2
6	32.09.22.2015	KARANG KENDAL	6	3209180017	KARANG KENDAL	2
7	32.09.22.2016	GROGOL	7	3209180018	GROGOL	1
8	32.09.22.2017	KAPETAKAN	8	3209180020	KAPETAKAN	2
9	32.09.22.2018	BUNGKO LOR	9	3209180021	BUNGKO LOR	2

Catatan :
*) 1. Perkotaan
2. Perdesaan

https://jabar.bps.go.id

PROVINSI : [32] JAWA BARAT
KAB/KOTA : [09] CIREBON
KECAMATAN : [181] SURANENGGALA

Data Kemendagri			MFD 2021 Semester 2			
No	Kode	Nama Desa	No	Kode	Nama DESA	Status*
1	32.09.39.2003	SURANENGGA-RA KULON	1	3209181001	SURANENGGA-RA KULON	2
2	32.09.39.2004	SURAKARTA	2	3209181002	SURAKARTA	1
3	32.09.39.2005	KERATON	3	3209181003	KERATON	1
4	32.09.39.2006	PURWAWI NANGUN	4	3209181004	PURWAWI NANGUN	1
5	32.09.39.2007	MUARA	5	3209181005	MUARA	2
6	32.09.39.2008	KARANGREJA	6	3209181006	KARANGREJA	1
7	32.09.39.2009	SURANENGGA-LA KIDUL	7	3209181007	SURANENGGA-LA KIDUL	2
8	32.09.39.2010	SURANENGGA-RA LOR	8	3209181008	SURANENGGA-RA LOR	1
9	32.09.39.2011	SURANENG-GALA	9	3209181009	SURANENG-GALA	2

https://jabar.bps.go.id

Catatan :
*) 1. Perkotaan
2. Perdesaan

DAFTAR DESA/KELURAHAN

PROVINSI : [32] JAWA BARAT
KAB/KOTA : [09] CIREBON
KECAMATAN : [190] KLANGENAN

Data Kemendagri			MFD 2021 Semester 2			
No	Kode	Nama Desa	No	Kode	Nama Desa	Status*
1	32.09.23.2001	SERANG	1	3209190001	SERANG	1
2	32.09.23.2002	KLANGENAN	2	3209190002	KLANGENAN	1
3	32.09.23.2003	DANAWINANG UN	3	3209190003	DANAWINANG UN	1
4	32.09.23.2007	PAKANTINGAN	4	3209190007	PEKANTINGAN	1
5	32.09.23.2008	JEMARAS KIDUL	5	3209190008	JEMARAS KIDUL	1
6	32.09.23.2009	JEMARAS LOR	6	3209190009	JEMARAS LOR	1
7	32.09.23.2010	SLANGIT	7	3209190011	SLANGIT	2
8	32.09.23.2011	KREYO	8	3209190012	KREYO	2
9	32.09.23.2012	BANGODUA	9	3209190013	BANGODUA	2

Catatan :
*) 1. Perkotaan
2. Perdesaan

https://jabar.bps.go.id

PROVINSI : [32] JAWA BARAT
KAB/KOTA : [09] CIREBON
KECAMATAN : [191] JAMBLANG

Data Kemendagri			MFD 2021 Semester 2			
No	Kode	Nama Desa	No	Kode	Nama Desa	Status*
1	32.09.40.2001	JAMBLANG	1	3209191004	JAMBLANG	1
2	32.09.40.2002	SITIWINANGUN	2	3209191005	SITIWINANGUN	1
3	32.09.40.2003	WANGUNHAR-JA	3	3209191006	WANGUNHAR-JA	1
4	32.09.40.2004	BOJONG WETAN	4	3209191014	BOJONG WETAN	2
5	32.09.40.2005	BOJONG LOR	5	3209191015	BOJONG LOR	2
6	32.09.39.2006	ORIMALANG	6	3209191016	ORIMALANG	2
7	32.09.40.2007	BAKUNG KIDUL	7	3209191017	BAKUNG KIDUL	2
8	32.09.40.2008	BAKUNG LOR	8	3209191018	BAKUNG LOR	2

Catatan :
*) 1. Perkotaan
2. Perdesaan

https://jabar.bps.go.id

DAFTAR DESA/KELURAHAN

PROVINSI : [32] JAWA BARAT
KAB/KOTA : [09] CIREBON
KECAMATAN : [200] ARJAWINANGUN

Data Kemendagri			MFD 2021 Semester 2			
No	Kode	Nama Desa	No	Kode	Nama Desa	Status*
1	32.09.24.2001	SENDE	1	3209200001	SENDE	2
2	32.09.24.2002	JUNGJANG WETAN	2	3209200002	JUNGJANG WETAN	1
3	32.09.24.2003	JUNGJANG	3	3209200010	JUNGJANG	1
4	32.09.24.2004	ARJAWINANG UN	4	3209200011	ARJAWINANG UN	1
5	32.09.24.2005	TEGALGUBUG	5	3209200012	TEGALGUBUG	1
6	32.09.24.2007	RAWAGATEL	6	3209200013	RAWAGATEL	1
7	32.09.24.2006	TEGAL GUBUG LOR	7	3209200014	TEGAL GUBUG LOR	1
8	32.09.24.2008	KARANGSAM-BUNG	8	3209200015	KARANGSAM-BUNG	1
9	32.09.24.2009	BULAK	9	3209200016	BULAK	2
10	32.09.24.2010	GEYONGAN	10	3209200017	GEYONGAN	1
11	32.09.24.2011	KEBONTURI	11	3209200018	KEBONTURI	1

Catatan :
*) 1. Perkotaan
2. Perdesaan

https://jabar.bps.go.id

PROVINSI : [32] JAWA BARAT
KAB/KOTA : [09] CIREBON
KECAMATAN : [201] PANGURAGAN

Data Kemendagri			MFD 2021 Semester 2			
No	Kode	Nama Desa	No	Kode	Nama Desa	Status*
1	32.09.25.2001	KALIANYAR	1	3209201001	KALIANYAR	1
2	32.09.25.2002	PANGURAGAN KULON	2	3209201002	PANGURAGAN KULON	1
3	32.09.25.2003	PANGURAGAN WETAN	3	3209201003	PANGURAGAN WETAN	1
4	32.09.25.2004	PANGURAGAN LOR	4	3209201004	PANGURAGAN LOR	1
5	32.09.25.2005	PANGURAGAN	5	3209201005	PANGURAGAN	1
6	32.09.25.2006	GUJEG	6	3209201006	GUJEG	1
7	32.09.25.2007	LEMAHTAMBA	7	3209201007	LEMAHTAMBA	1
8	32.09.25.2008	KARANG ANYAR	8	3209201008	KARANG ANYAR	2
9	32.09.25.2009	KROYA	9	3209201009	KROYA	2

https://jabar.bps.go.id

Catatan :
*) 1. Perkotaan
2. Perdesaan

DAFTAR DESA/KELURAHAN

PROVINSI : [32] JAWA BARAT
KAB/KOTA : [09] CIREBON
KECAMATAN : [210] CIWARINGIN

Data Kemendagri			MFD 2021 Semester 2			
No	Kode	Nama Desa	No	Kode	Nama Desa	Status*
1	32.09.26.2006	CIWARINGIN	1	3209210004	CIWARINGIN	1
2	32.09.26.2005	BABAKAN	2	3209210005	BABAKAN	1
3	32.09.26.2004	BUDUR	3	3209210006	BUDUR	1
4	32.09.26.2007	GINTUNGRAN-JENG	4	3209210007	GINTUNGRAN-JENG	2
5	32.09.26.2008	GINTUNG KIDUL	5	3209210008	GINTUNG KIDUL	2
6	32.09.26.2009	GINTUNG TENGAH	6	3209210009	GINTUNG TENGAH	2
7	32.09.26.2010	BRINGIN	7	3209210010	BRINGIN	2
8	32.09.26.2011	GALAGAMBA	8	3209210011	GALAGAMBA	2

Catatan :
*) 1. Perkotaan
2. Perdesaan

https://jabar.bps.go.id

PROVINSI : [32] JAWA BARAT
KAB/KOTA : [09] CIREBON
KECAMATAN : [211] GEMPOL

Data Kemendagri			MFD 2021 Semester 2			
No	Kode	Nama Desa	No	Kode	Nama Desa	Status*
1	32.09.37.2004	CUPANG	1	3209211001	CUPANG	2
2	32.09.37.2001	CIKEUSAL	2	3209211002	CIKEUSAL	2
3	32.09.37.2006	WALAHAR	3	3209211003	WALAHAR	1
4	32.09.37.2002	PALIMANAN BARAT	4	3209211004	PALIMANAN BARAT	1
5	32.09.37.2005	GEMPOL	5	3209211005	GEMPOL	1
6	32.09.37.2003	KEDUNG-BUNDER	6	3209211006	KEDUNG-BUNDER	1
7	32.09.37.2007	KEMPEK	7	3209211007	KEMPEK	1
8	32.09.37.2008	WINONG	8	3209211008	WINONG	1

Catatan :
*) 1. Perkotaan
2. Perdesaan

https://jabar.bps.go.id

DAFTAR DESA/KELURAHAN

PROVINSI : [32] JAWA BARAT
KAB/KOTA : [09] CIREBON
KECAMATAN : [220] SUSUKAN

Data Kemendagri			MFD 2021 Semester 2			
No	Kode	Nama Desa	No	Kode	Nama Desa	Status*
1	32.09.27.2001	TANGKIL	1	3209220001	TANGKIL	2
2	32.09.27.2002	WIYONG	2	3209220002	WIYONG	2
3	32.09.27.2003	KEDONGDONG	3	3209220003	KEDONGDONG	1
4	32.09.27.2004	GINTUNG LOR	4	3209220004	GINTUNG LOR	1
5	32.09.27.2005	BOJONG KULON	5	3209220005	BOJONG KULON	1
6	32.09.27.2006	KEJIWAN	6	3209220006	KEJIWAN	1
7	32.09.27.2007	SUSUKAN	7	3209220007	SUSUKAN	1
8	32.09.27.2008	LUWUNG KENCANA	8	3209220008	LUWUNG KENCANA	2
9	32.09.27.2009	BUNDER	9	3209220009	BUNDER	2
10	32.09.27.2010	JATIPURA	10	3209220010	JATIPURA	2
11	32.09.27.2011	UJUNGGE-BANG	11	3209220011	UJUNGGE-BANG	2
12	32.09.27.2012	JATIANOM	12	3209220012	JATIANOM	2

https://jabar.bps.go.id

Catatan :
*) 1. Perkotaan
2. Perdesaan

PROVINSI : [32] JAWA BARAT
KAB/KOTA : [09] CIREBON
KECAMATAN : [230] GEGESIK

Data Kemendagri			MFD 2021 Semester 2			
No	Kode	Nama Desa	No	Kode	Nama Desa	Status*
1	32.09.28.2014	BAYALANGU KIDUL	1	320930007	BAYALANGU KIDUL	2
2	32.09.28.2013	BAYALANGU LOR	2	320930008	BAYALANGU LOR	1
3	32.09.28.2001	KEDUNGDA-LEM	3	320930009	KEDUNGDA-LEM	2
4	32.09.28.2002	PANUNGGUL	4	320930010	PANUNGGUL	1
5	32.09.28.2003	GEGESIK WETAN	5	320930011	GEGESIK WETAN	1
6	32.09.28.2004	GEGESIK KIDUL	6	320930012	GEGESIK KIDUL	2
7	32.09.28.2007	SLENDRA	7	320930016	SLENDRA	2
8	32.09.28.2008	JAGAPURA KIDUL	8	320930017	JAGAPURA KIDUL	1
9	32.09.28.2005	GEGESIK LOR	9	320930018	GEGESIK LOR	1
10	32.09.28.2006	GEGESIK KULON	10	320930019	GEGESIK KULON	1
11	32.09.28.2009	JAGAPURA WETAN	11	320930020	JAGAPURA WETAN	1
12	32.09.28.2010	JAGAPUREA KULON	12	320930021	JAGAPUREA KULON	2
13	32.09.28.2011	JAGAPURA LOR	13	320930022	JAGAPURA LOR	1
14	32.09.28.2012	SIBUBUT	14	320930023	SIBUBUT	2

Catatan :
*) 1. Perkotaan
2. Perdesaan

https://jabar.bps.go.id

DAFTAR DESA/KELURAHAN

PROVINSI : [32] JAWA BARAT
KAB/KOTA : [09] CIREBON
KECAMATAN : [231] KALIWEDI

Data Kemendagri			MFD 2021 Semester 2			
No	Kode	Nama Desa	No	Kode	Nama Desa	Status*
1	32.09.29.2001	KALIDERES	1	3209231001	KALIDERES	2
2	32.09.29.2003	PRAJAWINANG UN WETAN	2	3209231002	PRAJAWINANG UN WETAN	1
3	32.09.29.2023	PRAJAWINANG UN KULON	3	3209231003	PRAJAWINANG UN KULON	2
4	32.09.29.2007	KALIWEDI KIDUL	4	3209231004	KALIWEDI KIDUL	2
5	32.09.29.2006	KALIWEDI LOR	5	3209231005	KALIWEDI LOR	2
6	32.09.29.2004	UJUNGSEMI	6	3209231006	UJUNGSEMI	2
7	32.09.29.2005	WARGA BINANGUN	7	3209231007	WARGA BINANGUN	2
8	32.09.29.2008	GUWA KIDUL	8	3209231008	GUWA KIDUL	2
9	32.09.29.2009	GUWA LOR	9	3209231009	GUWA LOR	2

https://jabar.bps.go.id

Catatan :
*) 1. Perkotaan
2. Perdesaan

KABUPATEN MAJALENGKA

https://jabar.bps.go.id

https://jabar.bps.go.id

PROVINSI : [32] JAWA BARAT
KAB/KOTA : [10] MAJALENGKA

Data Kemendagri			MFD 2021 Semester 2		
No	Kode	Nama Kecamatan	No	Kode	Nama Kecamatan
1	32.10.01	LEMAHSUGIH	1	3210010	LEMAHSUGIH
2	32.10.02	BANTARUJEG	2	3210020	BANTARUJEG
3	32.10.26	MALAUSMA	3	3210021	MALAUSMA
4	32.10.03	CIKIJING	4	3210030	CIKIJING
5	32.10.23	CINGAMBUL	5	3210031	CINGAMBUL
6	32.10.04	TALAGA	6	3210040	TALAGA
7	32.10.22	BANJARAN	7	3210041	BANJARAN
8	32.10.05	ARGAPURA	8	3210050	ARGAPURA
9	32.10.06	MAJA	9	3210060	MAJA
10	32.10.07	MAJALENGKA	10	3210070	MAJALENGKA
11	32.10.20	CIGASONG	11	3210080	CIGASONG
12	32.10.08	SUKAHAJI	12	3210090	SUKAHAJI
13	32.10.25	SINDANG	13	3210091	SINDANG
14	32.10.09	RAJAGALUH	14	3210100	RAJAGALUH
15	32.10.21	SINDANGWANGI	15	3210110	SINDANGWANGI
16	32.10.10	LEUWIMUNDING	16	3210120	LEUWIMUNDING
17	32.10.19	PALASAH	17	3210130	PALASAH
18	32.10.11	JATIWANGI	18	3210140	JATIWANGI
19	32.10.12	DAWUAN	19	3210150	DAWUAN
20	32.10.24	KASOKANDEL	20	3210151	KASOKANDEL
21	32.10.18	PANYINGKIRAN	21	3210160	PANYINGKIRAN
22	32.10.13	KADIPATEN	22	3210170	KADIPATEN
23	32.10.14	KERTAJATI	23	3210180	KERTAJATI
24	32.10.15	JATITUJUH	24	3210190	JATITUJUH
25	32.10.16	LIGUNG	25	3210200	LIGUNG
26	32.10.17	SUMBERJAYA	26	3210210	SUMBERJAYA

https://jabar.bps.go.id

JUMLAH DESA/KELURAHAN PER KECAMATAN

PROVINSI : [32] JAWA BARAT
KAB/KOTA : [10] MAJALENGKA

Data Kemendagri				MFD 2021 Semester 2			
No	Kode	Nama Kecamatan	Jml Desa	No	Kode	Nama Kecamatan	Jml Desa
1	32.10.01	LEMAHSUGIH	19	1	3210010	LEMAHSUGIH	19
2	32.10.02	BANTARUJEG	13	2	3210020	BANTARUJEG	13
3	32.10.26	MALAUSMA	11	3	3210021	MALAUSMA	11
4	32.10.03	CIKIJING	15	4	3210030	CIKIJING	15
5	32.10.23	CINGAMBUL	13	5	3210031	CINGAMBUL	13
6	32.10.04	TALAGA	17	6	3210040	TALAGA	17
7	32.10.22	BANJARAN	13	7	3210041	BANJARAN	13
8	32.10.05	ARGAPURA	14	8	3210050	ARGAPURA	14
9	32.10.06	MAJA	18	9	3210060	MAJA	18
10	32.10.07	MAJALENGKA	14	10	3210070	MAJALENGKA	14
11	32.10.20	CIGASONG	10	11	3210080	CIGASONG	10
12	32.10.08	SUKAHAJI	13	12	3210090	SUKAHAJI	13
13	32.10.25	SINDANG	7	13	3210091	SINDANG	7
14	32.10.09	RAJAGALUH	13	14	3210100	RAJAGALUH	13
15	32.10.21	SINDANGWANGI	10	15	3210110	SINDANGWANGI	10
16	32.10.10	LEUWIMUNDING	14	16	3210120	LEUWIMUNDING	14
17	32.10.19	PALASAH	13	17	3210130	PALASAH	13
18	32.10.11	JATIWANGI	16	18	3210140	JATIWANGI	16
19	32.10.12	DAWUAN	11	19	3210150	DAWUAN	11
20	32.10.24	KASOKANDEL	10	20	3210151	KASOKANDEL	10
21	32.10.18	PANYINGKIRAN	9	21	3210160	PANYINGKIRAN	9
22	32.10.13	KADIPATEN	7	22	3210170	KADIPATEN	7
23	32.10.14	KERTAJATI	14	23	3210180	KERTAJATI	14
24	32.10.15	JATITUJUH	15	24	3210190	JATITUJUH	15
25	32.10.16	LIGUNG	19	25	3210200	LIGUNG	19
26	32.10.17	SUMBERJAYA	15	26	3210210	SUMBERJAYA	15

https://jabar.bps.go.id

PROVINSI : [32] JAWA BARAT
KAB/KOTA : [10] MAJALENGKA
KECAMATAN : [010] LEMAHSUGIH

Data Kemendagri			MFD 2021 Semester 2			
No	Kode	Nama Desa	No	Kode	Nama Desa	Status*
1	32.10.01.2001	CIPASUNG	1	3210010001	CIPASUNG	2
2	32.10.01.2003	BOROGOJOL	2	3210010002	BOROGOJOL	2
3	32.10.01.2002	BANGBAYANG	3	3210010003	BANGBAYANG	2
4	32.10.01.2004	CIBULAN	4	3210010004	CIBULAN	2
5	32.10.01.2005	LEMAHPUTIH	5	3210010005	LEMAH PUTIH	2
6	32.10.01.2006	SADAWANGI	6	3210010006	SADAWANGI	2
7	32.10.01.2011	MARGAJAYA	7	3210010007	MARGAJAYA	1
8	32.10.01.2009	KALAPADUA	8	3210010008	KALAPADUA	2
9	32.10.01.2010	CIGALEUH	9	3210010009	CIGALEUH	2
10	32.10.01.2015	MEKARMULYA	10	3210010010	MEKARMULYA	2
11	32.10.01.2014	SINARGALIH	11	3210010011	SINARGALIH	2
12	32.10.01.2008	PADAREK	12	3210010012	PADAREK	2
13	32.10.01.2012	SUKAJADI	13	3210010013	SUKAJADI	2
14	32.10.01.2007	KEPUH	14	3210010014	KEPUH	2
15	32.10.01.2013	MEKARWANGI	15	3210010015	MEKAR WANGI	2
16	32.10.01.2016	SUKAMAJU	16	3210010016	SUKAMAJU	2
17	32.10.01.2019	LEMAHSUGIH	17	3210010017	LEMAHSUGIH	2
18	32.10.01.2018	DAYEUHWANGI	18	3210010018	DAYEUHWANGI	2
19	32.10.01.2017	CISALAK	19	3210010019	CISALAK	2

Catatan :
*) 1. Perkotaan
2. Perdesaan

https://jabar.bps.go.id

DAFTAR DESA/KELURAHAN

PROVINSI : [32] JAWA BARAT
KAB/KOTA : [10] MAJALEGKA
KECAMATAN : [020] BANTARUJEG

Data Kemendagri			MFD 2021 Semester 2			
No	Kode	Nama Desa	No	Kode	Nama Desa	Status*
1	32.10.02.2022	SINDANGHU-RIP	1	3210020009	SINDANGHU-RIP	2
2	32.10.02.2002	CIPEUNDEUY	2	3210020010	CIPEUNDEUY	2
3	32.10.02.2008	CIMANGGU-HILIR	3	3210020012	CIMANGGU-HILIR	2
4	32.10.02.2009	SALAWANGI	4	3210020013	SALAWANGI	2
5	32.10.02.2018	SILIHWANGI	5	3210020014	SILIHWANGI	2
6	32.10.02.2016	WADOWETAN	6	3210020015	WADOWETAN	2
7	32.10.02.2010	BANTARUJEG	7	3210020016	BANTARUJEG	1
8	32.10.02.2017	BABAKANSARI	8	3210020017	BABAKANSARI	2
9	32.10.02.2011	GUNUNG LARANG	9	3210020018	GUNUNG LARANG	2
10	32.10.02.2012	CIKIDANG	10	3210020019	CIKIDANG	2
11	32.10.02.2013	CINAMBO	11	3210020020	CINAMBO	2
12	32.10.02.2014	HAURGEULIS	12	3210020021	HAURGEULIS	2
13	32.10.02.2015	SUKAMENAK	13	3210020022	SUKAMENAK	2

Catatan :
*) 1. Perkotaan
2. Perdesaan

https://jabar.bps.go.id

PROVINSI : [32] JAWA BARAT
KAB/KOTA : [10] MAJALENGKA
KECAMATAN : [021] MALAUSMA

Data Kemendagri			MFD 2021 Semester 2			
No	Kode	Nama Desa	No	Kode	Nama Desa	Status*
1	32.10.26.2008	BUNINAGARA	1	3210021001	BUNINAGARA	2
2	32.10.26.2002	WERASARI	2	3210021002	WERASARI	2
3	32.10.26.2003	MALAUSMA	3	3210021003	MALAUSMA	1
4	32.10.26.2007	BANYUSARI	4	3210021004	BANYUSARI	1
5	32.10.26.2009	JAGAMULYA	5	3210021005	JAGAMULYA	2
6	32.10.26.2005	CIMUNCANG	6	3210021006	CIMUNCANG	2
7	32.10.26.2006	CIRANCA	7	3210021007	CIRANCA	2
8	32.10.26.2004	LEBAKWANGI	8	3210021008	LEBAKWANGI	2
9	32.10.26.2001	SUKADANA	9	3210021009	SUKADANA	2
10	32.10.26.2010	GIRIMUKTI	10	3210021010	GIRIMUKTI	2
11	32.10.26.2011	KRAMAT JAYA	11	3210021011	KRAMATJAYA	2

Catatan :
*) 1. Perkotaan
2. Perdesaan

https://jabar.bps.go.id

DAFTAR DESA/KELURAHAN

PROVINSI : [32] JAWA BARAT
KAB/KOTA : [10] MAJALENGKA
KECAMATAN : [030] CIKIJING

Data Kemendagri			MFD 2021 Semester 2			
No	Kode	Nama Desa	No	Kode	Nama Desa	Status*
1	32.10.03.2002	CISOKA	1	3210030014	CISOKA	2
2	32.10.03.2003	SINDANGPANJI	2	3210030015	SINDANGPANJI	1
3	32.10.03.2004	CIKIJING	3	3210030016	CIKIJING	1
4	32.10.03.2008	CIDULANG	4	3210030017	CIDULANG	1
5	32.10.03.2014	SUKAMUKTI	5	3210030018	SUKAMUKTI	1
6	32.10.03.2007	KASTURI	6	3210030019	KASTURI	1
7	32.10.03.2006	BANJARANSARI	7	3210030020	BANJARANSARI	1
8	32.10.03.2005	SINDANG	8	3210030021	SINDANG	2
9	32.10.03.2001	SUKASARI	9	3210030022	SUKASARI	2
10	32.10.03.2011	SUNALARI	10	3210030023	SUNALARI	2
11	32.10.03.2010	BAGJASARI	11	3210030024	BAGJASARI	2
12	32.10.03.2009	JAGASARI	12	3210030025	JAGASARI	1
13	32.10.03.2015	CILANCANG	13	3210030026	CILANGCANG	2
14	32.10.03.2013	KENCANA	14	3210030027	KENCANA	2
15	32.10.03.2012	CIPULUS	15	3210030028	CIPULUS	2

Catatan :
*) 1. Perkotaan
2. Perdesaan

https://jabar.bps.go.id

PROVINSI : [32] JAWA BARAT
KAB/KOTA : [10] MAJALENGKA
KECAMATAN : [031] CINGAMBUL

Data Kemendagri			MFD 2021 Semester 2			
No	Kode	Nama Desa	No	Kode	Nama Desa	Status*
1	32.10.23.2001	SEDARAJA	1	3210031001	SEDARAJA	2
2	32.10.23.2012	CINTAASIH	2	3210031002	CINTAASIH	2
3	32.10.23.2002	CIDADAP	3	3210031003	CIDADAP	2
4	32.10.23.2003	MANIIS	4	3210031004	MANIIS	2
5	32.10.23.2010	RAWA	5	3210031005	RAWA	2
6	32.10.23.2004	NAGARAKEM-BANG	6	3210031006	NAGARAKEM-BANG	2
7	32.10.23.2005	WANGKELANG	7	3210031007	WANGKELANG	2
8	32.10.23.2006	CIMANGGU GIRANG	8	3210031008	CIMANGGU	2
9	32.10.23.2009	CIRANJENG	9	3210031009	CIRANJENG	2
10	32.10.23.2007	CINGAMBUL	10	3210031010	CINGAMBUL	2
11	32.10.23.2013	MUKTISARI	11	3210031011	MUKTISARI	2
12	32.10.23.2008	CIKONDANG	12	3210031012	CIKONDANG	2
13	32.10.23.2011	KONDANG MEKAR	13	3210031013	KONDANG MEKAR	2

http://jabar.bps.go.id

Catatan :
*) 1. Perkotaan
2. Perdesaan

DAFTAR DESA/KELURAHAN

PROVINSI : [32] JAWA BARAT
KAB/KOTA : [10]MAJALENGKA
KECAMATAN : [040] TALAGA

Data Kemendagri			MFD 2021 Semester 2			
No	Kode	Nama Desa	No	Kode	Nama Desa	Status*
1	32.10.04.2016	MARGAMUKTI	1	3210040001	MARGAMUKTI	2
2	32.10.04.2002	CIBEUREUM	2	3210040002	CIBEUREUM	2
3	32.10.04.2003	CIKEUSAL	3	3210040003	CIKEUSAL	2
4	32.10.04.2004	JATIPAMOR	4	3210040004	JATIPAMOR	2
5	32.10.04.2006	CICANIR	5	3210040005	CICANIR	1
6	32.10.04.2007	CAMPAGA	6	3210040006	CAMPAGA	2
7	32.10.04.2001	LAMPUYANG	7	3210040007	LAMPUYANG	2
8	32.10.04.2015	MEKARRA-HARJA	8	3210040008	MEKARRA-HARJA	2
9	32.10.04.2009	TALAGA KU-LON	9	3210040009	TALAGAKULON	1
10	32.10.04.2010	TALAGA WETAN	10	3210040010	TALAGAWETAN	1
11	32.10.04.2012	SALADO	11	3210040011	SALADO	1
12	32.10.04.2005	ARGASARI	12	3210040012	ARGASARI	2
13	32.10.04.2013	GUNUNG-MANIK	13	3210040013	GUNUNG-MANIK	2
14	32.10.04.2011	GANEAS	14	3210040014	GANEAS	1
15	32.10.04.2008	SUKAPERNA	15	3210040015	SUKAPERNA	2
16	32.10.04.2014	KERTAHAYU	16	3210040016	KERTARAHAYU	2
17	32.10.04.2017	MEKARHURIP	17	3210040017	MEKARHURIP	2

Catatan :
*) 1. Perkotaan
2. Perdesaan

https://jabar.bps.go.id

PROVINSI : [32] JAWA BARAT
KAB/KOTA : [10] MAJALENGKA
KECAMATAN : [041] BANJARAN

Data Kemendagri			MFD 2021 Semester 2			
No	Kode	Nama Desa	No	Kode	Nama Desa	Status*
1	32.10.22.2001	GENTENG	1	3210041001	GENTENG	1
2	32.10.22.2012	HEGARMANAH	2	3210041002	HEGARMANAH	2
3	32.10.22.2004	SINDANGPALA	3	3210041003	SINDANGPALA	2
4	32.10.22.2003	DARMALA-RANG	4	3210041004	DARMALA-RANG	2
5	32.10.22.2011	SUNIA BARU	5	3210041005	SUNIABARU	2
6	32.10.22.2010	SANGIANG	6	3210041006	SANGIANG	2
7	32.10.22.2002	SUNIA	7	3210041007	SUNIA	2
8	32.10.22.2009	KAREO	8	3210041008	KAREO	2
9	32.10.22.2005	BANJARAN	9	3210041009	BANJARAN	2
10	32.10.22.2006	KAGOK	10	3210041009	KAGOK	2
11	32.10.22.2007	CIMEONG	11	3210041009	CIMEONG	2
12	32.10.22.2008	PANYINDANG AN	12	3210041009	PANYINDANG AN	2
13	32.10.22.2013	GIRIMULYA	13	3210041009	GIRIMULYA	2

Catatan :
*) 1. Perkotaan
2. Perdesaan

https://jabar.bps.go.id

DAFTAR DESA/KELURAHAN

PROVINSI : [32] JAWA BARAT
KAB/KOTA : [10] MAJALENGKA
KECAMATAN : [050] ARGAPURA

Data Kemendagri			MFD 2021 Semester 2			
No	Kode	Nama Desa	No	Kode	Nama Desa	Status*
1	32.10.05.2001	SAGARA	1	3210050001	SAGARA	2
2	32.10.05.2002	CIBUNUT	2	3210050002	CIBUNUT	2
3	32.10.05.2003	TEJAMULYA	3	3210050003	TEJAMULYA	2
4	32.10.05.2012	SUKASARI KIDUL	4	3210050004	SUKASARI KIDUL	1
5	32.10.05.2004	SUKASARI KALER	5	3210050005	SUKASARI KALER	1
6	32.10.05.2007	SADASARI	6	3210050006	SADASARI	1
7	32.10.05.2006	SUKADANA	7	3210050007	SUKADANA	2
8	32.10.05.2005	ARGAMUKTI	8	3210050008	ARGAMUKTI	2
9	32.10.05.2014	ARGALINGGA	9	3210050009	ARGALINGGA	2
10	32.10.05.2008	HAURSEAH	10	3210050010	HAURSEAH	2
11	32.10.05.2013	GUNUNG WANGI	11	3210050011	GUNUNG WANGI	2
12	32.10.05.2009	MEKARWANGI	12	3210050012	MEKARWANGI	2
13	32.10.05.2011	HEUBEULISUK	13	3210050013	HEUBEULISUK	2
14	32.10.05.2010	CIKARACAK	14	3210050014	CIKARACAK	2

Catatan :
*) 1. Perkotaan
2. Perdesaan

https://jabar.bps.go.id

PROVINSI : [32] JAWA BARAT
KAB/KOTA : [10] MAJALENGKA
KECAMATAN : [060] MAJA

Data Kemendagri			MFD 2021 Semester 2			
No	Kode	Nama Desa	No	Kode	Nama Desa	Status*
1	32.10.06.2001	CIHAUR	1	3210060001	CIHAUR	2
2	32.10.06.2002	WANAHAYU	2	3210060002	WANAHAYU	2
3	32.10.06.2003	CENGAL	3	3210060003	CENGAL	2
4	32.10.06.2004	ANGGRAWATI	4	3210060004	ANGGRAWATI	2
5	32.10.06.2005	CIPICUNG	5	3210060005	CICPICUNG	2
6	32.10.06.2006	MALONGPONG	6	3210060006	MALONGPONG	1
7	32.10.06.2007	TEGALSARI	7	3210060007	TEGALSARI	1
8	32.10.06.2017	MAJA SELATAN	8	3210060008	MAJA SELATAN	1
9	32.10.06.2008	MAJA UTARA	9	3210060009	MAJA UTARA	1
10	32.10.06.2009	PASANGGRA-HAN	10	3210060010	PASANGGRA-HAN	1
11	32.10.06.2010	CIEURIH	11	3210060011	CIEURIH	2
12	32.10.06.2012	KERTABASUKI	12	3210060012	KERTABASUKI	2
13	32.10.06.2013	SINDANGKER-TA	13	3210060013	SINDANGKER-TA	2
14	32.10.06.2014	BANJARAN	14	3210060014	BANJARAN	1
15	32.10.06.2015	PANIIS	15	3210060015	PANIIS	1
16	32.10.06.2016	CICALUNG	16	3210060016	CICALUNG	1
17	32.10.06.2017	PAGERAJI	17	3210060017	PAGERAJI	2
18	32.10.06.2018	NUNUK BARU	18	3210060018	NUNUK BARU	2

https://jabar.bps.go.id

Catatan :
*) 1. Perkotaan
2. Perdesaan

DAFTAR DESA/KELURAHAN

PROVINSI : [32] JAWA BARAT
KAB/KOTA : [10] MAJALENGKA
KECAMATAN : [070] MAJALENGKA

Data Kemendagri			MFD 2021 Semester 2			
No	Kode	Nama Desa	No	Kode	Nama Desa	Status*
1	32.10.07.1002	BABAKAN JAWA	1	3210070001	BABAKAN JAWA	1
2	32.10.07.2014	CIBODAS	2	3210070002	CIBODAS	2
3	32.10.07.2005	KULUR	3	3210070003	KULUR	2
4	32.10.07.2006	KAWUNG GIRANG	4	3210070004	KAWUNG GIRANG	1
5	32.10.07.1004	SINDANG-KASIH	5	3210070005	SINDANG-KASIH	1
6	32.10.07.1003	CICURUG	6	3210070006	CICURUG	1
7	32.10.07.1007	MAJALENGKA WETAN	7	3210070007	MAJALENGKA WETAN	1
8	32.10.07.1011	TONJONG	8	3210070008	TONJONG	1
9	32.10.07.1009	TARIKOLOT	9	3210070009	TARIKOLOT	1
10	32.10.07.1010	CIKASARUNG	10	3210070010	CIKASARUNG	1
11	32.10.07.1013	CIJATI	11	3210070011	CIJATI	1
12	32.10.07.1008	MAJALENGKA KULON	12	3210070012	MAJALENGKA KULON	1
13	32.10.07.1001	MUNJUL	13	3210070013	MUNJUL	2
14	32.10.07.2012	SIDAMUKTI	14	3210070014	SIDAMUKTI	2

Catatan :
*) 1. Perkotaan
2. Perdesaan

https://jabar.bps.go.id

PROVINSI : [32] JAWA BARAT
KAB/KOTA : [10] MAJALENGKA
KECAMATAN : [080] CIGASONG

Data Kemendagri			MFD 2021 Semester 2			
No	Kode	Nama Desa	No	Kode	Nama Desa	Status*
1	32.10.20.2001	KAWUNGHILIR	1	3210080001	KAWUNGHILIR	2
2	32.10.20.2002	TAJUR	2	3210080002	TAJUR	2
3	32.10.20.1004	CIGASONG	3	3210080003	CIGASONG	1
4	32.10.20.1005	SIMPEUREUM	4	3210080004	SIMPEUREUM	1
5	32.10.20.2003	TENJOLAYAR	5	3210080005	TENJOLAYAR	2
6	32.10.20.2009	KUTAMANGGU	6	3210080006	KUTAMANGGU	2
7	32.10.20.1006	CICENANG	7	3210080007	CICENANG	1
8	32.10.20.2007	BARIBIS	8	3210080008	BARIBIS	1
9	32.10.20.2008	BATUJAYA	9	3210080009	BATUJAYA	2
10	32.10.20.2010	KARAYUNAN	10	3210080010	KARAYUNAN	2

https://jabar.bps.go.id

Catatan :
*) 1. Perkotaan
2. Perdesaan

DAFTAR DESA/KELURAHAN

PROVINSI : [32] JAWA BARAT
KAB/KOTA : [10] MAJALENGKA
KECAMATAN : [090]SUKAHAJI

Data Kemendagri			MFD 2021 Semester 2			
No	Kode	Nama Desa	No	Kode	Nama Desa	Status*
1	32.10.08.2019	CANDRAJAYA	1	3210090001	CANDRAJAYA	2
2	32.10.08.2001	CIOMAS	2	3210090001	CIOMAS	2
3	32.10.08.2002	PADAHANTEN	3	3210090001	PADAHANTEN	1
4	32.10.08.2009	SUKAHAJI	4	3210090001	SUKAHAJI	1
5	32.10.08.2018	CIKALONG	5	3210090001	CIKALONG	1
6	32.10.08.2016	BABAKAN-MANJETI	6	3210090001	BABAKAN MANJETI	2
7	32.10.08.2015	CIKONENG	7	3210090001	CIKONENG	1
8	32.10.08.2014	PALABUAN	8	3210090001	PALABUAN	2
9	32.10.08.2011	CIKEUSIK	9	3210090001	CIKEUSIK	2
10	32.10.08.2010	SALAGEDANG	10	3210090001	SALAGEDANG	2
11	32.10.08.2017	TANJUNGSARI	11	3210090001	TANJUNGSARI	1
12	32.10.08.2012	JAYI	12	3210090001	JAYI	2
13	32.10.08.2013	NANGGEWER	13	3210090001	NANGGEWER	2

Catatan :
*) 1. Perkotaan
2. Perdesaan

https://jabar.bps.go.id

PROVINSI : [32] JAWA BARAT
KAB/KOTA : [10] MAJALENGKA
KECAMATAN : [091]SINDANG

Data Kemendagri			MFD 2021 Semester 2			
No	Kode	Nama Desa	No	Kode	Nama Desa	Status*
1	32.10.25.2001	PASIRAYU	1	3210091001	PASIRAYU	2
2	32.10.25.2002	GARAWASTU	2	3210091002	GARAWASTU	2
3	32.10.25.2003	SANGKAN HURIP	3	3210091003	SANGKAN HURIP	2
4	32.10.25.2004	INDRAKILA	4	3210091004	INDRAKILA	2
5	32.10.25.2005	SINDANG	5	3210091005	SINDANG	2
6	32.10.25.2006	GUNUNG KUNING	6	3210091006	GUNUNG KUNING	2
7	32.10.25.2007	BAYUREJA	7	3210091007	BAYUREJA	2

Catatan :
*) 1. Perkotaan
2. Perdesaan

https://jabar.bps.go.id

DAFTAR DESA/KELURAHAN

PROVINSI : [32] JAWA BARAT
KAB/KOTA : [10] MAJALENGKA
KECAMATAN : [100] RAJAGALUH

Data Kemendagri			MFD 2021 Semester 2			
No	Kode	Nama Desa	No	Kode	Nama Desa	Status*
1	32.10.09.2001	PAJAJAR	1	3210100001	PAJAJAR	2
2	32.10.09.2002	TEJA	2	3210100002	TEJA	2
3	32.10.09.2003	PAYUNG	3	3210100003	PAYUNG	2
4	32.10.09.2005	SINDANGPANO	4	3210100004	SINDANGPANO	2
5	32.10.09.2004	BABAKAN-KAREO	5	3210100005	BABAKAN-KAREO	2
6	32.10.09.2006	SADOMAS	6	3210100006	SADOMAS	2
7	32.10.09.2007	KUMBUNG	7	3210100007	KUMBUNG	1
8	32.10.09.2008	RAJAGALUH KIDUL	8	3210100008	RAJAGALUH KIDUL	1
9	32.10.09.2009	SINGAWADA	9	3210100009	SINGAWADA	1
10	32.10.09.2013	RAJAGALUH	10	3210100010	RAJAGALUH	1
11	32.10.09.2010	RAJAGALUH LOR	11	3210100011	RAJAGALUH LOR	1
12	32.10.09.2011	CIPINANG	12	3210100012	CIPINANG	1
13	32.10.09.2012	CISETU	13	3210100013	CISETU	1

Catatan :
*) 1. Perkotaan
2. Perdesaan

https://jabar.bps.go.id

PROVINSI : [32] JAWA BARAT
KAB/KOTA : [10] MAJALENGKA
KECAMATAN : [110] SINDANGWANGI

Data Kemendagri			MFD 2021 Semester 2			
No	Kode	Nama Desa	No	Kode	Nama Desa	Status*
1	32.10.21.2001	BANTARA-GUNG	1	3210110001	BANTAR AGUNG	2
2	32.10.21.2002	PADAHERANG	2	3210110002	PADAHERANG	2
3	32.10.21.2010	LENGKONG WETAN	3	3210110010	LENGKONG WETAN	1
4	32.10.21.2003	LENGKONG KULON	4	3210110003	LENGKONG KULON	2
5	32.10.21.2004	JERUKLEUEUT	5	3210110005	JERUKLEUEUT	2
6	32.10.21.2005	SINDANGWAN-GI	6	3210110006	SINDANGWAN-GI	1
7	32.10.21.2006	BUAHKAPAS	7	3210110007	BUAHKAPAS	1
8	32.10.21.2007	UJUNG BERUNG	8	3210110008	UJUNG BERUNG	1
9	32.10.21.2009	LEUWILAJA	9	3210110009	LEUWILAJA	1
10	32.10.21.2008	BALAGEDOG	10	3210110009	BALAGEDOG	2

Catatan :
*) 1. Perkotaan
2. Perdesaan

https://jabar.bps.go.id

DAFTAR DESA/KELURAHAN

PROVINSI : [32] JAWA BARAT
KAB/KOTA : [10] MAJALENGKA
KECAMATAN : [120] LEUWIMUNDING

Data Kemendagri			MFD 2021 Semester 2			
No	Kode	Nama Desa	No	Kode	Nama Desa	Status*
1	32.10.10.2001	PARAKAN	1	3210120001	PARAKAN	1
2	32.10.10.2004	LAME	2	3210120002	LAME	1
3	32.10.10.2005	MINDI	3	3210120003	MINDI	2
4	32.10.10.2006	RAJAWANGI	4	3210120004	RAJAWANGI	1
5	32.10.10.2007	LEUWIKUJANG	5	3210120005	LEUWIKUJANG	1
6	32.10.10.2003	NANGGERANG	6	3210120006	NANGGERANG	1
7	32.10.10.2002	PATUANAN	7	3210120007	PATUANAN	2
8	32.10.10.2013	TANJUNGSARI	8	3210120008	TANJUNGSARI	1
9	32.10.10.2012	KARANGASEM	9	3210120009	KARANGASEM	2
10	32.10.10.2011	HEULEUT	10	3210120010	HEULEUT	1
11	32.10.10.2010	CIPARAY	11	3210120011	CIPARAY	1
12	32.10.10.2009	LEUWIMUN-DING	12	3210120012	LEUWIMUN-DING	1
13	32.10.10.2008	MIRAT	13	3210120013	MIRAT	1
14	32.10.10.2014	PARUNGJAYA	14	3210120014	PARUNGJAYA	1

https://jabar.bps.go.id

Catatan :
*) 1. Perkotaan
2. Perdesaan

PROVINSI : [32] JAWA BARAT
KAB/KOTA : [10] MAJALENGKA
KECAMATAN : [130] PALASAH

Data Kemendagri			MFD 2021 Semester 2			
No	Kode	Nama Desa	No	Kode	Nama Desa	Status*
1	32.10.19.2004	WERAGATI	1	3210130001	WERAGATI	2
2	32.10.19.2005	TRAJAYA	2	321013002	TRAJAYA	2
3	32.10.19.2006	TARIKOLOT	3	3210130003	TARIKOLOT	2
4	32.10.19.2008	SINDANGHAJI	4	3210130004	SINDANGHAJI	2
5	32.10.19.2012	ENGGAL WANGI	5	3210130005	ENGGAL WANGI	2
6	32.10.19.2007	BUNIWANGI	6	3210130006	BUNIWANGI	2
7	32.10.19.2003	PALASAH	7	3210130007	PALASAH	1
8	32.10.19.2010	PASIR	8	3210130008	PASIR	2
9	32.10.19.2009	WARINGIN	9	3210130009	WARINGIN	2
10	32.10.19.2011	KARAMAT	10	3210130010	KARAMAT	1
11	32.10.19.2013	SINDANGWA-SA	11	3210130011	SINDANGWA-SA	1
12	32.10.19.2002	CISAMBENG	12	3210130012	CISAMBENG	1
13	32.10.19.2001	MAJASUKA	13	3210130013	MAJASUKA	2

Catatan :
*) 1. Perkotaan
2. Perdesaan

https://jabar.bps.go.id

DAFTAR DESA/KELURAHAN

PROVINSI : [32] JAWA BARAT
KAB/KOTA : [10] MAJALENGKA
KECAMATAN : [140] JATIWANGI

Data Kemendagri			MFD 2021 Semester 2			
No	Kode	Nama Desa	No	Kode	Nama Desa	Status*
1	32.10.11.2006	PINANGRAJA	1	3210140001	PINANGRAJA	1
2	32.10.11.2014	SUKARAJA KULON	2	3210140002	SUKARAJA KULON	1
3	32.10.11.2005	SUKARAJA WETAN	3	3210140003	SUKARAJA WETAN	1
4	32.10.11.2007	CIBENTAR	4	3210140004	CIBENTAR	2
5	32.10.11.2008	LEUWEUNG GEDE	5	3210140005	LEUWEUNG GEDE	1
6	32.10.11.2004	ANDIR	6	3210140006	ANDIR	1
7	32.10.11.2003	CICADAS	7	3210140007	CICADAS	1
8	32.10.11.2002	BURUJUL WETAN	8	3210140008	BURUJUL WETAN	1
9	32.10.11.2001	BURUJUL KULON	9	3210140009	BURUJUL KULON	1
10	32.10.11.2015	MEKARSARI	10	3210140010	MEKARSARI	1
11	32.10.11.2012	JATIWANGI	11	3210140011	JATIWANGI	1
12	32.10.11.2016	SURAWANGI	12	3210140012	SURAWANGI	1
13	32.10.11.2011	JATISURA	13	3210140013	JATISURA	1
14	32.10.11.2010	SUTAWANGI	14	3210140014	SUTAWANGI	1
15	32.10.11.2009	CIBORELANG	15	3210140015	CIBORELANG	1
16	32.10.11.2013	LOJI	16	3210140016	LOJI	1

Catatan :
*) 1. Perkotaan
2. Perdesaan

https://jabar.bps.go.id

PROVINSI : [32] JAWA BARAT
KAB/KOTA : [10] MAJALENGKA
KECAMATAN : [150]DAWUAN

Data Kemendagri			MFD 2021 Semester 2			
No	Kode	Nama Desa	No	Kode	Nama Desa	Status*
1	32.10.12.2015	BOJONG CIDERES	1	3210150011	BOJONG CIDERES	1
2	32.10.12.2007	DAWUAN	2	3210150012	DAWUAN	1
3	32.10.12.2008	GENTENG	3	3210150013	GENTENG	2
4	32.10.12.2006	GANDU	4	3210150014	GANDU	1
5	32.10.12.2017	SINARJATI	5	3210150015	SINARJATI	1
6	32.10.12.2021	BATURUYUK	6	3210150016	BATURUYUK	1
7	32.10.12.2010	MANDAPA	7	3210150017	MANDAPA	1
8	32.10.12.2011	BALIDA	8	3210150018	BALIDA	2
9	32.10.12.2018	PASIRMALATI	9	3210150019	PASIRMALATI	2
10	32.10.12.2012	KARANG ANYAR	10	3210150020	KARANG ANYAR	2
11	32.10.12.2013	SALAWANA	11	3210150021	SALAWANA	2

Catatan :
*) 1. Perkotaan
2. Perdesaan

https://jabar.bps.go.id

DAFTAR DESA/KELURAHAN

PROVINSI : [32] JAWA BARAT
KAB/KOTA : [10] MAJALENGKA
KECAMATAN : [151] KASOKANDEL

Data Kemendagri			MFD 2021 Semester 2			
No	Kode	Nama Desa	No	Kode	Nama Desa	Status*
1	32.10.24.2001	JATISAWIT	1	3210151001	JATISAWIT	2
2	32.10.24.2002	LEUWIKIDANG	2	3210151002	LEUWIKIDANG	1
3	32.10.24.2003	GIRIMUKTI	3	3210151003	GIRIMUKTI	1
4	32.10.24.2004	JATIMULYA	4	3210151004	JATIMULYA	2
5	32.10.24.2005	WANAJAYA	5	3210151005	WANAJAYA	2
6	32.10.24.2006	RANJI WETAN	6	3210151006	RANJIWETAN	2
7	32.10.24.2007	RANJI KULON	7	3210151007	RANJIKULON	1
8	32.10.24.2008	GUNUNGSARI	8	3210151008	GUNUNGSARI	1
9	32.10.24.2009	KASOKANDEL	9	3210151009	KASOKANDEL	1
10	32.10.24.2010	GANDASARI	10	3210151010	GANDASARI	1

https://jabar.bps.go.id

Catatan :
*) 1. Perkotaan
2. Perdesaan

PROVINSI : [32] JAWA BARAT
KAB/KOTA : [10] MAJALENGKA
KECAMATAN : [160] PANYINGKIRAN

Data Kemendagri			MFD 2021 Semester 2			
No	Kode	Nama Desa	No	Kode	Nama Desa	Status*
1	32.10.18.2001	CIJUREY	1	3210160001	CIJUREY	2
2	32.10.18.2002	PASIRMUN-CANG	2	321016002	PASIRMUN-CANG	2
3	32.10.18.2003	JATIPAMOR	3	3210160003	JATIPAMOR	2
4	32.10.18.2004	BANTRANG-SANA	4	3210160004	BANTRANG-SANA	2
5	32.10.18.2005	JATISERANG	5	3210160005	JATISERANG	2
6	32.10.18.2006	BONANG	6	3210160006	BONANG	2
7	32.10.18.2007	LEUWISEENG	7	3210160007	LEUWISEENG	2
8	32.10.18.2009	KARYAMUKTI	8	3210160008	KARYAMUKTI	1
9	32.10.18.2008	PANYINGKIRAN	9	3210160009	PANYINGKIRAN	2

Catatan :
*) 1. Perkotaan
2. Perdesaan

https://jabar.bps.go.id

DAFTAR DESA/KELURAHAN

PROVINSI : [32] JAWA BARAT
KAB/KOTA : [10] MAJALENGKA
KECAMATAN : [170] KADIPATEN

Data Kemendagri			MFD 2021 Semester 2			
No	Kode	Nama Desa	No	Kode	Nama Desa	Status*
1	32.10.13.2001	LIANGJULANG	1	3210170001	LIANGJULANG	1
2	32.10.13.2002	HEULEUT	2	3210170002	HEULEUT	2
3	32.10.13.2003	CIPAKU	3	3210170003	CIPAKU	2
4	32.10.13.2004	KADIPATEN	4	3210170004	KADIPATEN	1
5	32.10.13.2005	BABAKANAN-YAR	5	3210170005	BABAKAN ANYAR	2
6	32.10.13.2006	KARANGSAM-BUNG	6	3210170006	KARANGSAM-BUNG	1
7	32.10.13.2007	PAGANDON	7	3210170007	PAGANDON	1

Catatan :
*) 1. Perkotaan
2. Perdesaan

https://jabar.bps.go.id

PROVINSI : [32] JAWA BARAT
KAB/KOTA : [10] MAJALENGKA
KECAMATAN : [180] KERTAJATI

Data Kemendagri			MFD 2021 Semester 2			
No	Kode	Nama Desa	No	Kode	Nama Desa	Status*
1	32.10.14.2011	MEKARJAYA	1	3210180001	MEKARJAYA	2
2	32.10.14.2004	PALASAH	2	3210180002	PALASAH	2
3	32.10.14.2001	PAKUBEURE-UM	3	3210180003	PAKUBEURE-UM	2
4	32.10.14.2002	SUKAWANA	4	3210180004	SUKAWANA	2
5	32.10.14.2003	KERTAWINANG UN	5	3210180005	KERTAWINANG UN	2
6	32.10.14.2005	BABAKAN	6	3210180006	BABAKAN	1
7	32.10.14.2006	KERTAJATI	7	3210180007	KERTAJATI	2
8	32.10.14.2010	KERTASARI	8	3210180008	KERTASARI	2
9	32.10.14.2012	MEKARMULYA	9	3210180009	MEKARMULYA	2
10	32.10.14.2009	SUKAMULYA	10	3210180010	SUKAMULYA	2
11	32.10.14.2007	BANTARJATI	11	3210180011	BANTARJATI	2
12	32.10.14.2008	PASIRIPIS	12	3210180012	PASIRIPIS	2
13	32.10.14.2013	SUKAKERTA	13	3210180013	SUKAKERTA	2
14	32.10.14.2014	SAHBANDAR	14	3210180014	SAHBANDAR	2

Catatan :
*) 1. Perkotaan
2. Perdesaan

https://jabar.bps.go.id

DAFTAR DESA/KELURAHAN

PROVINSI : [32] JAWA BARAT
KAB/KOTA : [10] MAJALENGKA
KECAMATAN : [190] JATITUJUH

Data Kemendagri			MFD 2021 Semester 2			
No	Kode	Nama Desa	No	Kode	Nama Desa	Status*
1	32.10.15.2001	BIYAWAK	1	3210190001	BIYAWAK	2
2	32.10.15.2015	PASINDANGAN	2	3210190002	PASINDANGAN	2
3	32.10.15.2003	PANONGAN	3	3210190003	PANONGAN	2
4	32.10.15.2002	PANYINGKIRAN	4	3210190004	PANYINGKIRAN	2
5	32.10.15.2013	RANDEGAN KULON	5	3210190005	RANDEGAN KULON	2
6	32.10.15.2004	RANDEGAN WETAN	6	3210190006	RANDEGAN WETAN	2
7	32.10.15.2005	PUTRIDALEM	7	3210190007	PUTRIDALEM	2
8	32.10.15.2006	JATITENGAH	8	3210190008	JATITENGAH	1
9	32.10.15.2007	JATITUJUH	9	3210190009	JATITUJUH	1
10	32.10.15.2008	BABAJURANG	10	3210190010	BABAJURANG	2
11	32.10.15.2009	PILANGSARI	11	3210190011	PILANGSARI	2
12	32.10.15.2010	JATIRAGA	12	3210190012	JATIRAGA	2
13	32.10.15.2014	SUMBER KULON	13	3210190013	SUMBER KULON	2
14	32.10.15.2011	SUMBER WETAN	14	3210190014	SUMBER WETAN	2
15	32.10.15.2012	PANGKALAN PARI	15	3210190015	PANGKALAN PARI	2

Catatan :
*) 1. Perkotaan
2. Perdesaan

https://jabar.bps.go.id

PROVINSI : [32] JAWA BARAT
KAB/KOTA : [10] MAJALENGKA
KECAMATAN : [200] LIGUNG

Data Kemendagri			MFD 2021 Semester 2			
No	Kode	Nama Desa	No	Kode	Nama Desa	Status*
1	32.10.16.2001	CIBOGOR	1	3210200001	CIBOGOR	2
2	32.10.16.2012	KERTASARI	2	3210200002	KERTASARI	2
3	32.10.16.2016	GANDAWESI	3	3210200003	GANDAWESI	2
4	32.10.16.2003	BEUSI	4	3210200004	BEUSI	2
5	32.10.16.2004	TEGALAREN	5	3210200005	TEGALAREN	2
6	32.10.16.2005	BUNTU	6	3210200006	BUNTU	2
7	32.10.16.2002	BEBER	7	3210200007	BEBER	2
8	32.10.16.2007	WANASALAM	8	3210200008	WANASALAM	2
9	32.10.16.2014	LIGUNG LOR	9	3210200009	LIGUNG LOR	1
10	32.10.16.2006	LIGUNG	10	3210200010	LIGUNG	1
11	32.10.16.2010	MAJASARI	11	3210200011	MAJASARI	2
12	32.10.16.2015	SUKAWERA	12	3210200012	SUKAWERA	2
13	32.10.16.2009	BANTARWARU	13	3210200013	BANTARWARU	1
14	32.10.16.2008	AMPEL	14	3210200014	AMPEL	2
15	32.10.16.2013	LEUWEUNG-HAPIT	15	3210200015	LEUWEUNG-HAPIT	2
16	32.10.16.2017	KODASARI	16	3210200016	KODASARI	2
17	32.10.16.2011	KEDUNGKEN-CANA	17	3210200017	KEDUNGKAN-CANA	2
18	32.10.16.2018	LEUWILIANG BARU	18	3210200018	LEUWILIANG BARU	2
19	32.10.16.2019	KEDUNGSARI	19	3210200019	KEDUNGSARI	2

Catatan :
*) 1. Perkotaan
2. Perdesaan

https://jabar.bps.go.id

DAFTAR DESA/KELURAHAN

PROVINSI : [32] JAWA BARAT
KAB/KOTA : [10] MAJALENGKA
KECAMATAN : [210] SUMBERJAYA

Data Kemendagri			MFD 2021 Semester 2			
No	Kode	Nama Desa	No	Kode	Nama Desa	Status*
1	32.10.17.2013	SUMBERJAYA	1	3210210001	SUMBERJAYA	1
2	32.10.17.2003	GARAWANGI	2	3210210002	GARAWANGI	2
3	32.10.17.2005	BANJARAN	3	3210210003	BANJARAN	1
4	32.10.17.2006	SEPAT	4	3210210004	SEPAT	1
5	32.10.17.2007	PANINGKIRAN	5	3210210005	PANINGKIRAN	1
6	32.10.17.2008	PARAPATAN	6	3210210006	PARAPATAN	1
7	32.10.17.2009	PANJALIN KIDUL	7	3210210007	PANJALIN KIDUL	1
8	32.10.17.2004	RANCAPUTAT	8	3210210008	RANCAPUTAT	1
9	32.10.17.2001	BONGAS WETAN	9	3210210009	BONGAS WETAN	2
10	32.10.17.2002	BONGAS KULON	10	3210210010	BONGAS KULON	1
11	32.10.17.2012	PANJALIN LOR	11	3210210011	PANJALIN LOR	1
12	32.10.17.2010	CIDENOK	12	3210210012	CIDENOK	2
13	32.10.17.2011	LOJI KOBONG	13	3210210013	LOJIKOBONG	2
14	32.10.17.2015	GELOK MULYA	14	3210210014	GELOKMULYA	1
15	32.10.17.2014	PANCAKSUJI	15	3210210015	PANCAKSUJI	1

Catatan :
*) 1. Perkotaan
2. Perdesaan

https://jabar.bps.go.id

KABUPATEN SUMEDANG

https://jabar.bps.go.id

https://jabar.bps.go.id

PROVINSI : [32] JAWA BARAT
KAB/KOTA : [11] SUMEDANG

Data Kemendagri			MFD 2021 Semester 2		
No	Kode	Nama Kecamatan	No	Kode	Nama Kecamatan
1	32.11.15	JATINANGOR	1	3211010	JATINANGOR
2	32.11.14	CIMANGGUNG	2	3211020	CIMANGGUNG
3	32.11.11	TANJUNGSARI	3	3211030	TANJUNGSARI
4	32.11.12	SUKASARI	4	3211031	SUKASARI
5	32.11.13	PAMULIHAN	5	3211032	PAMULIHAN
6	32.11.16	RANCAKALONG	6	3211040	RANCAKALONG
7	32.11.17	SUMEDANG SELATAN	7	3211050	SUMEDANG SELATAN
8	32.11.18	SUMEDANG UTARA	8	3211060	SUMEDANG UTARA
9	32.11.19	GANEAS	9	3211061	GANEAS
10	32.11.06	SITURAJA	10	3211070	SITURAJA
11	32.11.05	CISITU	11	3211071	CISITU
12	32.11.03	DARMARAJA	12	3211080	DARMARAJA
13	32.11.04	CIBUGEL	13	3211190	CIBUGEL
14	32.11.01	WADO	14	3211100	WADO
15	32.11.02	JATINUNGGAL	15	3211101	JATINUNGGAL
16	32.11.26	JATIGEDE	16	3211111	JATIGEDE
17	32.11.24	TOMO	17	3211120	TOMO
18	32.11.25	UJUNGJAYA	18	3211130	UJUNG JAYA
19	32.11.07	CONGGEANG	19	3211140	CONGGEANG
20	32.11.08	PASEH	20	3211150	PASEH
21	32.11.22	CIMALAKA	21	3211160	CIMALAKA
22	32.11.23	CISARUA	22	3211161	CISARUA
23	32.11.20	TANJUNGKERTA	23	3211170	TANJUNG KERTA
24	32.11.21	TANJUNGMEDAR	24	3211171	TANJUNG MEDAR
25	32.11.10	BUAHDUA	25	3211180	BUAHDUA
26	32.11.09	SURIAN	26	3211081	SURIAN

https://jabar.bps.go.id

JUMLAH DESA/KELURAHAN PER KECAMATAN

PROVINSI : [32] JAWA BARAT
KAB/KOTA : [11] SUMEDANG

Data Kemendagri				MFD 2021 Semester 2			
No	Kode	Nama Kecamatan	Jml desa	No	Kode	Nama Kecamatan	Jml Desa
1	32.11.15	JATINANGOR	12	1	3211010	JATINANGOR	12
2	32.11.14	CIMANGGUNG	11	2	3211020	CIMANGGUNG	11
3	32.11.11	TANJUNGSARI	12	3	3211030	TANJUNGSARI	12
4	32.11.12	SUKASARI	7	4	3211031	SUKASARI	7
5	32.11.13	PAMULIHAN	11	5	3211032	PAMULIHAN	11
6	32.11.16	RANCAKALONG	10	6	3211040	RANCAKALONG	10
7	32.11.17	SUMEDANG SELATAN	14	7	3211050	SUMEDANG SELATAN	14
8	32.11.18	SUMEDANG UTARA	13	8	3211060	SUMEDANG UTARA	13
9	32.11.19	GANEAS	8	9	3211061	GANEAS	8
10	32.11.06	SITURAJA	15	10	3211070	SITURAJA	15
11	32.11.05	CISITU	10	11	3211071	CISITU	10
12	32.11.03	DARMARAJA	12	12	3211080	DARMARAJA	12
13	32.11.04	CIBUGEL	7	13	3211090	CIBUGEL	7
14	32.11.01	WADO	10	14	3211100	WADO	10
15	32.11.02	JATINUNGGAL	9	15	3211101	JATINUNGGAL	9
16	32.11.26	JATIGEDE	11	16	3211111	JATIGEDE	11
17	32.11.24	TOMO	9	17	3211120	TOMO	9
18	32.11.25	UJUNGJAYA	9	18	3211130	UJUNG JAYA	9
19	32.11.07	CONGGEANG	12	19	3211140	CONGGEANG	12
20	32.11.08	PASEH	10	20	3211150	PASEH	10
21	32.11.22	CIMALAKA	14	21	3211160	CIMALAKA	14
22	32.11.23	CISARUA	7	22	3211161	CISARUA	7
23	32.11.20	TANJUNGKERTA	12	23	3211170	TANJUNG KERTA	12
24	32.11.21	TANJUNGMEDAR	9	24	3211171	TANJUNG MEDAR	9
25	32.11.10	BUAHDUA	14	25	3211180	BUAHDUA	14
26	32.11.09	SURIAN	9	26	3211181	SURIAN	9

https://jabar.bps.go.id

PROVINSI : [32] JAWA BARAT
KAB/KOTA : [11] SUMEDANG
KECAMATAN : [010] JATINANGOR

Data Kemendagri			MFD 2021 Semester 2			
No	Kode	Nama Desa	No	Kode	Nama Desa	Status*
1	32.11.15.2004	CIPACING	1	3211010001	CIPACING	1
2	32.11.15.2005	SAYANG	2	3211010002	SAYANG	1
3	32.11.15.2006	MEKARGALIH	3	3211010003	MEKARGALIH	1
4	32.11.15.2007	CINTAMULYA	4	3211010004	CINTA MULYA	1
5	32.11.15.2009	CISEMPUR	5	3211010005	CISEMPUR	1
6	32.11.15.2008	JATIMUKTI	6	3211010006	JATIMUKTI	1
7	32.11.15.2010	JATIROKE	7	3211010007	JATIROKE	1
8	32.11.15.2002	HEGARMANAH	8	3211010008	HEGARMANAH	1
9	32.11.15.2001	CIKERUH	9	3211010009	CIKERUH	1
10	32.11.15.2003	CIBEUSI	10	3211010010	CIBEUSI	1
11	32.11.15.2011	CILELES	11	3211010011	CILELES	1
12	32.11.15.2012	CILAYUNG	12	3211010012	CILAYUNG	1

Catatan :
*) 1. Perkotaan
2. Perdesaan

https://jabar.bps.go.id

DAFTAR DESA/KELURAHAN

PROVINSI : [32] JAWA BARAT
KAB/KOTA : [11] SUMEDANG
KECAMATAN : [020] CIMANGGUNG

Data Kemendagri			MFD 2021 Semester 2			
No	Kode	Nama Desa	No	Kode	Nama Desa	Status*
1	32.11.14.2009	MANGUNAR-GA	1	3211020001	MANGUNAR-GA	1
2	32.11.14.2006	SAWAHDADAP	2	3211020002	SAWAHDADAP	1
3	32.11.14.2008	SUKADANA	3	3211020003	SUKADANA	1
4	32.11.14.2010	CIHANJUANG	4	3211020004	CIHANJUANG	1
5	32.11.14.2007	CIKAHURIPAN	5	3211020005	CIKAHURIPAN	2
6	32.11.14.2005	SINDANGGA-LIH	6	3211020006	SINDANGGA-LIH	1
7	32.11.14.2002	SINDANGPA-KUON	7	3211020007	SINDANGPA-KUON	1
8	32.11.14.2001	CIMANGGUNG	8	3211020008	CIMANGGUNG	2
9	32.11.14.2003	TEGALMANG-GUNG	9	3211020009	TEGALMANG-GUNG	2
10	32.11.14.2004	SINDULANG	10	3211020010	SINDULANG	2
11	32.11.14.2011	PASIRNAN-JUNG	11	3211020011	PASIRNAN-JUNG	1

Catatan :
*) 1. Perkotaan
2. Perdesaan

https://jabar.bps.go.id

PROVINSI : [32] JAWA BARAT
KAB/KOTA : [11] SUMEDANG
KECAMATAN : [030] TANJUNGSARI

Data Kemendagri			MFD 2021 Semester 2			
No	Kode	Nama Desa	No	Kode	Nama Desa	Status*
1	32.11.11.2012	CINANJUNG	1	3211030001	CINANJUNG	
2	32.11.11.2007	RAHARJA	2	3211030002	RAHARJA	
3	32.11.11.2010	GUNUNG-MANIK	3	3211030003	GUNUNG-MANIK	
4	32.11.11.2006	MARGAJAYA	4	3211030004	MARGA JAYA	
5	32.11.11.2002	TANJUNGSARI	5	3211030005	TANJUNGSARI	
6	32.11.11.2003	JATISARI	6	3211030006	JATISARI	
7	32.11.11.2005	KUTAMANDIRI	7	3211030007	KUTAMANDIRI	
8	32.11.11.2004	MARGALUYU	8	3211030008	MARGALUYU	
8	32.11.11.2001	GUDANG	8	3211030009	GUDANG	
9	32.11.11.2009	PASIGARAN	9	3211030010	PASIGARAN	
10	32.11.11.2011	KADAKAJAYA	10	3211030011	KADAKAJAYA	
11	32.11.11.2008	CIJAMBU	11	3211030012	CIJAMBU	

Catatan :
*) 1. Perkotaan
2. Perdesaan

https://jabar.bps.go.id

DAFTAR DESA/KELURAHAN

PROVINSI : [32] JAWA BARAT
KAB/KOTA : [11] SUMEDANG
KECAMATAN : [031] SUKASARI

Data Kemendagri			MFD 2021 Semester 2			
No	Kode	Nama Desa	No	Kode	Nama Desa	Status*
1	32.11.12.2007	SUKARAPIH	1	3211031001	SUKARAPIH	1
2	32.11.12.2001	SUKASARI	2	3211031002	SUKASARI	2
3	32.11.12.2005	MEKARSARI	3	3211031003	MEKARSARI	2
4	32.11.12.2006	SINDANGSARI	4	3211031004	SINDANGSARI	2
5	32.11.12.2004	NANGGERANG	5	3211031005	NANGGERANG	2
6	32.11.12.2003	BANYURESMI	6	3211031006	BANYURESMI	2
7	32.11.12.2002	GENTENG	7	3211031007	GENTENG	2

Catatan :
*) 1. Perkotaan
2. Perdesaan

https://jabar.bps.go.id

PROVINSI : [32] JAWA BARAT
KAB/KOTA : [11] SUMEDANG
KECAMATAN : [032] PAMULIHAN

Data Kemendagri			MFD 2021 Semester 2			
No	Kode	Nama Desa	No	Kode	Nama Desa	Status*
1	32.11.13.2001	MEKARBAKTI	1	321032001	MEKARBAKTI	2
2	32.11.13.2002	CILEMBU	2	321032002	CILEMBU	2
3	32.11.13.2003	CIMARIAS	3	321032003	CIMARIAS	2
4	32.11.13.2004	CINANG-GERANG	4	321032004	CINANG-GERANG	2
5	32.11.13.2005	CIJERUK	5	321032005	CIJERUK	2
6	32.11.13.2006	CIGENDEL	6	321032006	CIGENDEL	2
7	32.11.13.2007	HAURGOM-BONG	7	321032007	HAURNGOM-BONG	1
8	32.11.13.2008	CIPTASARI	8	321032008	CIPTASARI	1
9	32.11.13.2009	CITALI	9	321032009	CITALI	2
10	32.11.13.2010	PAMULIHAN	10	321032010	PAMULIHAN	1
11	32.11.13.2011	SUKAWANGI	11	321032011	SUKAWANGI	2

Catatan :
*) 1. Perkotaan
2. Perdesaan

https://jabar.bps.go.id

DAFTAR DESA/KELURAHAN

PROVINSI : [32] JAWA BARAT
KAB/KOTA : [11] SUMEDANG
KECAMATAN : [040] RANCAKALONG

Data Kemendagri			MFD 2021 Semester 2			
No	Kode	Nama Desa	No	Kode	Nama Desa	Status*
1	32.11.16.2008	SUKASIRNARA-SA	1	3211040002	SUKASIRNARA-SA	2
2	32.11.16.2010	PASIRBIRU	2	3211040006	PASIR BIRU	2
3	32.11.16.2007	RANCAKA-LONG	3	3211040007	RANCAKA-LONG	2
4	32.11.16.2006	PAMEKARAN	4	3211040008	PAMEKARAN	2
5	32.11.16.2005	SUKAMAJU	5	3211040009	SUKAMAJU	2
6	32.11.16.2004	SUKAHAYU	6	3211040010	SUKAHAYU	2
7	32.11.16.2001	NAGARA WANGI	7	3211040011	NAGARA WANGI	2
8	32.11.16.2002	CIBUNAR	8	3211040012	CIBUNAR	2
9	32.11.16.2003	PANGADEGAN	9	3211040013	PANGADEGAN	2
10	32.11.16.2009	CIBUNGUR	10	3211040014	CIBUNGUR	2

Catatan :
*) 1. Perkotaan
2. Perdesaan

https://jabar.bps.go.id

PROVINSI : [32] JAWA BARAT
KAB/KOTA : [11] SUMEDANG
KECAMATAN : [050] SUMEDANG SELATAN

Data Kemendagri			MFD 2021 Semester 2			
No	Kode	Nama Desa	No	Kode	Nama Desa	Status*
1	32.11.17.2010	SUKAJAYA	1	3211050001	SUKAJAYA	1
2	32.11.17.2011	MARGAMEKAR	2	3211050002	MARGAMEKAR	1
3	32.11.17.2007	CIPANCAR	3	3211050003	CIPANCAR	2
4	32.11.17.2008	CITENGAH	4	3211050004	CITENGAH	2
5	32.11.17.2009	GUNASARI	5	3211050007	GUNASARI	2
6	32.11.17.2006	BAGINDA	6	3211050008	BAGINDA	1
7	32.11.17.2005	SUKAGALIH	7	3211050009	SUKAGALIH	1
8	32.11.17.1004	CIPAMEUNG-PEUK	8	3211050010	CIPAMEUNG-PEUK	1
9	32.11.17.1003	REGOLWETAN	9	3211050011	REGOL WETAN	1
10	32.11.17.1002	KOTAKULON	10	3211050012	KOTAKULON	1
11	32.11.17.1001	PASANGGRA HAN BARU	11	3211050013	PASANGGRA HAN BARU	1
12	32.11.17.2012	CIHERANG	12	3211050014	CIHERANG	2
13	32.11.17.2014	MEKAR RA-HAYU	13	3211050015	MEKARRA-HAYU	1
14	32.11.17.2013	MARGALAK-SANA	14	3211050016	MARGALAK-SANA	1

Catatan :
*) 1. Perkotaan
2. Perdesaan

https://jabar.bps.go.id

DAFTAR DESA/KELURAHAN

PROVINSI : [32] JAWA BARAT
KAB/KOTA : [11] SUMEDANG
KECAMATAN : [060] SUMEDANG UTARA

Data Kemendagri			MFD 2021 Semester 2			
No	Kode	Nama Desa	No	Kode	Nama Desa	Status*
1	32.11.18.2009	SIRNAMULYA	1	3211060001	SIRNAMULYA	2
2	32.11.18.2006	GIRIMUKTI	2	3211060002	GIRIMUKTI	1
3	32.11.18.2005	MULYASARI	3	3211060003	MULYASARI	2
4	32.11.18.2004	PADASUKA	4	3211060004	PADASUKA	1
5	32.11.18.2008	MARGAMUKTI	5	3211060005	MARGAMUKTI	2
6	32.11.18.2007	MEKARJAYA	6	3211060006	MEKARJAYA	1
7	32.11.18.2012	JATIMULYA	7	3211060007	JATIMULYA	1
8	32.11.18.2011	JATIHURIP	8	3211060008	JATIHURIP	1
9	32.11.18.2010	KEBONJATI	9	3211060009	KEBONJATI	1
10	32.11.18.1002	SITU	10	3211060010	SITU	1
11	32.11.18.1001	KOTAKALER	11	3211060011	KOTAKALER	1
12	32.11.18.1003	TALUN	12	3211060012	TALUN	1
13	32.11.18.2013	RANCAMULYA	13	3211060013	RANCAMULYA	1

Catatan :
*) 1. Perkotaan
2. Perdesaan

https://jabar.bps.go.id

PROVINSI : [32] JAWA BARAT
KAB/KOTA : [11] SUMEDANG
KECAMATAN : [061] GANEAS

Data Kemendagri			MFD 2021 Semester 2			
No	Kode	Nama Desa	No	Kode	Nama DESA	Status*
1	32.11.19.2007	CIKONDANG	1	3211061001	CIKONDANG	2
2	32.11.19.2006	TANJUNGHU-RIP	2	3211061002	TANJUNGHU-RIP	1
3	32.11.19.2002	DAYEUH LUHUR	3	3211061003	DAYEUH LUHUR	2
4	32.11.19.2003	CIKONENG	4	3211061004	CIKONENG	2
5	32.11.19.2005	SUKAWENING	5	3211061005	SUKAWENING	2
6	32.11.19.2001	GANEAS	6	3211061006	GANEAS	2
7	32.11.19.2004	SUKALUYU	7	3211061007	SUKALUYU	2
8	32.11.19.2008	CIKONENG KULON	8	3211061008	CIKONENG KULON	2

Catatan :
*) 1. Perkotaan
2. Perdesaan

https://jabar.bps.go.id

DAFTAR DESA/KELURAHAN

PROVINSI : [32] JAWA BARAT
KAB/KOTA : [11] SUMEDANG
KECAMATAN : [070] SITURAJA

Data Kemendagri			MFD 2021 Semester 2			
No	Kode	Nama Desa	No	Kode	Nama Desa	Status*
1	32.11.06.2005	BANGBAYANG	1	3211070001	BANGBAYANG	2
2	32.11.06.2006	KADUWULUNG	2	3211070002	KADUWULUNG	2
3	32.11.06.2011	CIJATI	3	3211070003	CIJATI	2
4	32.11.06.2003	MEKARMULYA	4	3211070004	MEKARMULYA	1
5	32.11.06.2004	CIKADU	5	3211070005	CIKADU	2
6	32.11.06.2007	KARANGHEU-LEUT	6	3211070006	KARANGHEU-LEUT	2
7	32.11.06.2008	CIJELER	7	3211070007	CIJELER	2
8	32.11.06.2009	AMBIT	8	3211070008	AMBIT	2
9	32.11.06.2014	SUKATALI	9	3211070009	SUKATALI	2
10	32.11.06.2002	SITURAJA	10	3211070010	SITURAJA	1
11	32.11.06.2010	JATIMEKAR	11	3211070011	JATIMEKAR	1
12	32.11.06.2001	SITURAJA UTARA	12	3211070012	SITURAJA UTARA	1
13	32.11.06.2013	MALAKA	13	3211070013	MALAKA	1
14	32.11.06.2012	PAMULIHAN	14	3211070014	PAMULIHAN	2
15	32.11.06.2015	CICARIMANAH	16	3211070015	CICARIMANAH	2

Catatan :
*) 1. Perkotaan
2. Perdesaan

https://jabar.bps.go.id

PROVINSI : [32] JAWA BARAT
KAB/KOTA : [11] SUMEDANG
KECAMATAN : [071] CISITU

Data Kemendagri			MFD 2021 Semester 2			
No	Kode	Nama Desa	No	Kode	Nama Desa	Status*
1	32.11.05.2005	SUNDAMEKAR	1	3211071001	SUNDAMEKAR	2
2	32.11.05.2009	CIMARGA	2	3211071002	CIMARGA	2
3	32.11.05.2010	CINANGSI	3	3211071003	CINANGSI	2
4	32.11.05.2006	LINGGAJAYA	4	3211071004	LINGGAJAYA	2
5	32.11.05.2002	SITUMEKAR	5	3211071005	SITUMEKAR	2
6	32.11.05.2001	CISITU	6	3211071006	CISITU	2
7	32.11.05.2004	CIGINTUNG	7	3211071007	CIGINTUNG	2
8	32.11.05.2007	RANJENG	8	3211071008	RANJENG	2
9	32.11.05.2008	CILOPANG	9	3211071009	CILOPANG	2
10	32.11.05.2003	PAJAGAN	10	3211071010	PAJAGAN	2

https://jabar.bps.go.id

Catatan :
*) 1. Perkotaan
2. Perdesaan

DAFTAR DESA/KELURAHAN

PROVINSI : [32] JAWA BARAT
KAB/KOTA : [11] SUMEDANG
KECAMATAN : [080] DARMARAJA

Data Kemendagri			MFD 2021 Semester 2			
No	Kode	Nama Desa	No	Kode	Nama Desa	Status*
1	32.11.03.2013	NEGLASARI	1	3211080003	NEGLASARI	1
2	32.11.03.2003	SUKAMENAK	2	3211080004	SUKAMENAK	2
3	32.11.03.2002	DARMAJAYA	3	3211080006	DARMAJAYA	1
4	32.11.03.2001	DARMARAJA	4	3211080007	DARMARAJA	1
5	32.11.03.2007	CIPEUTEUY	5	3211080008	CIPEUTEUY	2
6	32.11.03.2006	CIKEUSI	6	3211080011	CIKEUSI	2
7	32.11.03.2009	CIEUNTEUNG	7	3211080012	CIEUNTEUNG	1
8	32.11.03.2015	TARUNAJAYA	8	3211080013	TARUNAJAYA	2
9	32.11.03.2005	SUKARATU	9	3211080014	SUKARATU	1
10	32.11.03.2010	KARANGPA-KUAN	10	3211080018	KARANG PA-KUAN	2
11	32.11.03.2011	PAKUALAM	11	3211080019	PAKU ALAM	2
12	32.11.03.2016	RANGGON	12	3211080020	RANGGON	2

Catatan :
*) 1. Perkotaan
2. Perdesaan

https://jabar.bps.go.id

PROVINSI : [32] JAWA BARAT
KAB/KOTA : [11] SUMEDANG
KECAMATAN : [090] CIBUGEL

Data Kemendagri			MFD 2021 Semester 2			
No	Kode	Nama Desa	No	Kode	Nama Desa	Status*
1	32.11.04.2002	BUANAMEKAR	1	3211090001	BUANA MEKAR	2
2	32.11.04.2001	JAYAMEKAR	2	3211090002	JAYA MEKAR	2
3	32.11.04.2003	CIBUGEL	3	3211090003	CIBUGEL	2
4	32.11.04.2006	TAMANSARI	4	3211090004	TAMANSARI	2
5	32.11.04.2004	SUKARAJA	5	3211090005	SUKARAJA	2
6	32.11.04.2005	CIPASANG	6	3211090006	CIPASANG	2
7	32.11.04.2007	JAYAMANDIRI	7	3211090007	JAYAMANDIRI	2

Catatan :
*) 1. Perkotaan
2. Perdesaan

https://jabar.bps.go.id

DAFTAR DESA/KELURAHAN

PROVINSI : [32] JAWA BARAT
KAB/KOTA : [11] SUMEDANG
KECAMATAN : [100] WADO

Data Kemendagri			MFD 2021 Semester 2			
No	Kode	Nama Desa	No	Kode	Nama Desa	Status*
1	32.11.01.2003	CILENGKRANG	1	3211100001	CILENGKRANG	2
2	32.11.01.2009	SUKAJADI	2	3211100002	SUKAJADI	2
3	32.11.01.2002	GANJARESIK	3	3211100003	GANJARESIK	2
4	32.11.01.2001	CIMUNGKAL	4	3211100004	CIMUNGKAL	2
5	32.11.01.2007	MULYAJAYA	5	3211100011	MULYAJAYA	2
6	32.11.01.2004	CIKAREO SELATAN	6	3211100012	CIKAREO SELATAN	2
7	32.11.01.2005	CIKAREO UTARA	7	3211100013	CIKAREO UTARA	2
8	32.11.01.2006	WADO	8	3211100014	WADO	1
9	32.11.01.2011	SUKAPURA	9	3211100016	SUKAPURA	2
10	32.11.01.2010	CISURAT	10	3211100017	CISURAT	2

Catatan :
*) 1. Perkotaan
2. Perdesaan

https://jabar.bps.go.id

PROVINSI : [32] JAWA BARAT
KAB/KOTA : [11] SUMEDANG
KECAMATAN : [101] JATINUNGGAL

Data Kemendagri			MFD 2021 Semester 2			
No	Kode	Nama Desa	No	Kode	Nama Desa	Status*
1	32.11.02.2006	KIRISIK	1	3211101001	KIRISIK	2
2	32.11.02.2008	CIPEUNDEUY	2	3211101002	CIPEUNDEUY	2
3	32.11.02.2009	CIMANINTIN	3	3211101003	CIMANINTIN	2
4	32.11.02.2007	SUKAMANAH	4	3211101004	SUKAMANAH	2
5	32.11.02.2005	BANJARSARI	5	3211101005	BANJARSARI	2
6	32.11.02.2004	SARIMEKAR	6	3211101006	SARIMEKAR	2
7	32.11.02.2002	TARIKOLOT	7	3211101007	TARIKOLOT	2
8	32.11.02.2001	SIRNASARI	8	3211101008	SIRNASARI	2
9	32.11.02.2003	PAWENANG	9	3211101009	PAWENANG	1

Catatan :
*) 1. Perkotaan
2. Perdesaan

https://jabar.bps.go.id

DAFTAR DESA/KELURAHAN

PROVINSI : [32] JAWA BARAT
KAB/KOTA : [11] SUMEDANG
KECAMATAN : [111] JATIGEDE

Data Kemendagri			MFD 2021 Semester 2			
No	Kode	Nama Desa	No	Kode	Nama Desa	Status*
1	32.11.26.2006	MEKARASIH	1	3211100002	MEKARASIH	2
2	32.11.26.2008	CIRANGGEM	2	3211100003	CIRANGGEM	2
3	32.11.26.2009	CISAMPIH	3	3211100004	CISAMPIH	2
4	32.11.26.2012	KADU	4	3211100006	KADU	2
5	32.11.26.2003	LEBAKSIUH	5	3211100007	LEBAKSIUH	2
6	32.11.26.2004	CINTAJAYA	6	3211100008	CINTAJAYA	2
7	32.11.26.2005	CIPICUNG	7	3211100009	CIPICUNG	2
8	32.11.26.2010	JEMAH	8	3211100010	JEMAH	2
9	32.11.26.2001	CIJEUNGJING	9	3211100011	CIJEUNGJING	2
10	32.11.26.2002	KADUJAYA	10	3211100012	KADUJAYA	2
11	32.11.26.2011	KAREDOK	11	3211100013	KAREDOK	2

https://jabar.bps.go.id

Catatan :
*) 1. Perkotaan
2. Perdesaan

PROVINSI : [32] JAWA BARAT
KAB/KOTA : [11] SUMEDANG
KECAMATAN : [120] TOMO

Data Kemendagri			MFD 2021 Semester 2			
No	Kode	Nama Desa	No	Kode	Nama Desa	Status*
1	32.11.24.2007	CIPELES	1	3211120003	CIPELES	2
2	32.11.24.2003	DARMAWANGI	2	3211120004	DARMAWANGI	2
3	32.11.24.2005	JEMBARWANGI	3	3211120005	JEMBARWANGI	2
4	32.11.24.2004	MARONGGE	4	3211120006	MARONGGE	2
5	32.11.24.2002	TOLENGAS	5	3211120007	TOLENGAS	1
6	32.11.24.2001	TOMO	6	3211120008	TOMO	1
7	32.11.24.2008	KARYAMUKTI	7	3211120009	KARYAMUKTI	2
8	32.11.24.2006	BUGEL	8	3211120010	BUGEL	2
9	32.11.24.2010	MEKARWANGI	9	3211120011	MEKARWANGI	2

Catatan :
*) 1. Perkotaan
2. Perdesaan

https://jabar.bps.go.id

DAFTAR DESA/KELURAHAN

PROVINSI : [32] JAWA BARAT
KAB/KOTA : [11] SUMEDANG
KECAMATAN : [130] UJUNGJAYA

Data Kemendagri			MFD 2021 Semester 2			
No	Kode	Nama Desa	No	Kode	Nama Desa	Status*
1	32.11.25.2008	CIPELANG	1	3211130001	CIPELANG	2
2	32.11.25.2002	PALABUAN	2	3211130002	PALABUAN	2
3	32.11.25.2004	KEBONCAU	3	3211130003	KEBON CAU	2
4	32.11.25.2006	KUDANG WANGI	4	3211130004	KUDANG WANGI	2
5	32.11.25.2007	SUKAMULYA	5	3211130005	SUKAMULYA	2
6	32.11.25.2003	PALASARI	6	3211130006	PALASARI	2
7	32.11.25.2001	UJUNGJAYA	7	3211130007	UJUNGJAYA	2
8	32.11.25.2005	SAKURJAYA	8	3211130008	SAKURJAYA	2
9	32.11.25.2009	CIBULUH	9	3211130009	CIBULUH	2

Catatan :
*) 1. Perkotaan
2. Perdesaan

https://jabar.bps.go.id

PROVINSI : [32] JAWA BARAT
KAB/KOTA : [11] SUMEDANG
KECAMATAN : [140] CONGGEANG

Data Kemendagri			MFD 2021 Semester 2			
No	Kode	Nama Desa	No	Kode	Nama Desa	Status*
1	32.11.07.2011	NARIMBANG	1	3211140001	NARIMBANG	2
2	32.11.07.2005	JAMBU	2	3211140002	JAMBU	2
3	32.11.07.2003	CIPAMEKAR	3	3211140003	CIPAMEKAR	2
4	32.11.07.2001	CONGGEANG KULON	4	3211140004	CONGGEANG KULON	1
5	32.11.07.2002	CONGGEANG WETAN	5	3211140005	CONGGEANG WETAN	2
6	32.11.07.2004	CIBEUREU YEUH	6	3211140006	CIBEUREU YEUH	1
7	32.11.07.2007	PADAASIH	7	3211140007	PADAASIH	2
8	32.11.07.2006	BABAKAN ASEM	8	3211140008	BABAKAN ASEM	2
9	32.11.07.2008	UNGKAL	9	3211140009	UNGKAL	2
10	32.11.07.2010	CACABAN	10	3211140010	CACABAN	2
11	32.11.07.2009	KARANG LAYUNG	11	3211140011	KARANG LAYUNG	2
12	32.11.07.2012	CIBUBUAN	12	3211140012	CIBUBUAN	2

https://jabar.bps.go.id

Catatan :
*) 1. Perkotaan
2. Perdesaan

DAFTAR DESA/KELURAHAN

PROVINSI : [32] JAWA BARAT
KAB/KOTA : [11] SUMEDANG
KECAMATAN : [150] PASEH

Data Kemendagri			MFD 2021 Semester 2			
No	Kode	Nama Desa	No	Kode	Nama Desa	Status*
1	32.11.08.2004	LEGOK KALER	1	3211150001	LEGOK KALER	1
2	32.11.08.2003	LEGOK KIDUL	2	3211150002	LEGOK KIDUL	2
3	32.11.08.2001	PASEHKIDUL	3	3211150003	PASEH KIDUL	1
4	32.11.08.2008	CIJAMBE	4	3211150004	CIJAMBE	2
5	32.11.08.2007	PASIRREUNGIT	5	3211150005	PASIREUNGIT	2
6	32.11.08.2006	PADANAN	6	3211150006	PADANAAN	2
7	32.11.08.2005	BONGKOK	7	3211150007	BONGKOK	2
8	32.11.08.2002	PASEH KALER	8	3211150008	PASEH KALER	2
9	32.11.08.2009	HAURKUNING	9	3211150009	HAURKUNING	2
10	32.11.08.2010	CITEPOK	10	3211150010	CITEPOK	2

https://jabar.bps.go.id

Catatan :
*) 1. Perkotaan
2. Perdesaan

PROVINSI : [32] JAWA BARAT
KAB/KOTA : [11] SUMEDANG
KECAMATAN : [160] CIMALAKA

Data Kemendagri			MFD 2021 Semester 2			
No	Kode	Nama Desa	No	Kode	Nama Desa	Status*
1	32.11.22.2014	CIMUJA	1	3211161001	CIMUJA	1
2	32.11.22.2008	CIBEUREUM WETAN	2	3211161011	CIBEUREUM WETAN	2
3	32.11.22.2003	CIBEUREUM KULON	3	3211161012	CIBEUREUM KULON	2
4	32.11.22.2009	MANDALA HERANG	4	3211161013	MANDALA HERANG	2
5	32.11.22.2001	CIMALAKA	5	3211161014	CIMALAKA	1
6	32.11.22.2012	SERANG	6	3211161015	SERANG	1
7	32.11.22.2002	GALUDRA	7	3211161016	GALUDRA	2
8	32.11.22.2007	CIKOLE	8	3211161017	CIKOLE	2
9	32.11.22.2006	TRUNAMANG-GALA	9	3211161018	TRUNAMANG-GALA	2
10	32.11.22.2005	NYALINDUNG	10	3211161019	NYALINDUNG	2
11	32.11.22.2004	NALUK	11	3211161020	NALUK	2
12	32.11.22.2011	CITIMUN	12	3211161021	CITIMUN	2
13	32.11.22.2010	LICIN	13	3211161022	LICIN	1
14	32.11.22.2013	PADASARI	14	3211161023	PADASARI	2

Catatan :
*) 1. Perkotaan
2. Perdesaan

https://jabar.bps.go.id

DAFTAR DESA/KELURAHAN

PROVINSI : [32] JAWA BARAT
KAB/KOTA : [11] SUMEDANG
KECAMATAN : [161] CISARUA

Data Kemendagri			MFD 2021 Semester 2			
No	Kode	Nama Desa	No	Kode	Nama Desa	Status*
1	32.11.23.2006	CISALAK	1	3211161001	CISALAK	2
2	32.11.23.2007	KEBONKALAPA	2	3211161002	KEBONKALAPA	1
3	32.11.23.2001	CISARUA	3	3211161003	CISARUA	2
4	32.11.23.2004	BANTARMARA	4	3211161004	BANTARMARA	2
5	32.11.23.2002	CIUYAH	5	3211161005	CIUYAH	2
6	32.11.23.2003	CIMARA	6	3211161006	CIMARA	2
7	32.11.23.2005	CIPANDAN-WANGI	7	3211161007	CIPANDAN-WANGI	2

Catatan :
*) 1. Perkotaan
2. Perdesaan

https://jabar.bps.go.id

PROVINSI : [32] JAWA BARAT
KAB/KOTA : [11] SUMEDANG
KECAMATAN : [170] TANJUNG KERTA

Data Kemendagri			MFD 2021 Semester 2			
No	Kode	Nama Desa	No	Kode	Nama Desa	Status*
1	32.11.20.2009	TANJUNG MEKAR	1	3211170001	TANJUNG MEKAR	2
2	32.11.20.2008	CIGENTUR	2	3211170002	CIGENTUR	1
3	32.11.20.2003	GUNTUR MEKAR	3	3211170003	GUNTUR MEKAR	2
4	32.11.20.2002	CIPANAS	4	3211170004	CIPANAS	2
5	32.11.20.2005	BANYUASIH	5	3211170005	BANYUASIH	2
6	32.11.20.2004	MULYAMEKAR	6	3211170006	MULYAMEKAR	2
7	32.11.20.2001	SUKAMANTRI	7	3211170007	SUKAMANTRI	2
8	32.11.20.2007	KERTARA-HARJA	8	3211170008	KERTARA-HARJA	2
9	32.11.20.2006	KERTAMEKAR	9	3211170009	KERTAMEKAR	2
10	32.11.20.2010	TANJUNG MULYA	10	3211170010	TANJUNG MULYA	2
11	32.11.20.2011	BAROS	11	3211170011	BOROS	2
12	32.11.20.2012	AWILEGA	12	3211170012	AWILEGA	2

Catatan :
*) 1. Perkotaan
2. Perdesaan

https://jabar.bps.go.id

DAFTAR DESA/KELURAHAN

PROVINSI : [32] JAWA BARAT
KAB/KOTA : [11] SUMEDANG
KECAMATAN : [171] TANJUNG MEDAR

Data Kemendagri			MFD 2021 Semester 2			
No	Kode	Nama Desa	No	Kode	Nama Desa	Status*
1	32.11.21.2002	WARGALUYU	1	3211171001	WARGALUYU	2
2	32.11.21.2006	TANJUNG-WANGI	2	3211171002	TANJUNG-WANGI	2
3	32.11.21.2007	SUKAMUKTI	3	3211171003	SUKAMUKTI	2
4	32.11.21.2001	CIKARAMAS	4	3211171004	CIKARAMAS	2
5	32.11.21.2005	KERTAMUKTI	5	3211171005	KERTAMUKTI	2
6	32.11.21.2008	SUKATANI	6	3211171006	SUKATANI	2
7	32.11.21.2004	KAMAL	7	3211171007	KAMAL	2
8	32.11.21.2003	JINGKANG	8	3211171008	JINGKANG	2
9	32.11.21.2009	TANJUNG MEDAR	9	3211171009	TANJUNGME-DAR	2

Catatan :
*) 1. Perkotaan
2. Perdesaan

https://jabar.bps.go.id

PROVINSI : [32] JAWA BARAT
KAB/KOTA : [11] SUMEDANG
KECAMATAN : [180] BUAH DUA

Data Kemendagri			MFD 2021 Semester 2			
No	Kode	Nama Desa	No	Kode	Nama Desa	Status*
1	32.11.10.2008	SEKARWANGI	1	3211180001	SEKARWANGI	1
2	32.11.10.2011	CILANGKAP	2	3211180002	CILANGKAP	2
3	32.11.10.2007	CIBITUNG	3	3211180003	CIBITUNG	2
4	32.11.10.2013	CIKURUBUK	4	3211180004	CIKURUBUK	2
5	32.11.10.2012	BOJONGLOA	5	3211180005	BOJONGLOA	2
6	32.11.10.2006	NAGRAK	6	3211180006	NAGRAK	2
7	32.11.10.2010	PANYINDAN-GAN	7	3211180007	PANYINDAN-GAN	2
8	32.11.10.2001	BUAHDUA	8	3211180008	BUAHDUA	2
9	32.11.10.2009	GENDEREH	9	3211180009	GENDEREH	2
10	32.11.10.2005	CITALEUS	10	3211180010	CITALEUS	2
11	32.11.10.2004	MEKARMUKTI	11	3211180011	MEKARMUKTI	2
12	32.11.10.2002	HARIANG	12	3211180012	HARIANG	1
13	32.11.10.2003	KARANG BUNGUR	13	3211180013	KARANG BUNGUR	2
14	32.11.10.2014	CIAWITALI	14	3211180014	CIAWITALI	2

Catatan :
*) 1. Perkotaan
2. Perdesaan

https://jabar.bps.go.id

DAFTAR DESA/KELURAHAN

PROVINSI : [32] JAWA BARAT
KAB/KOTA : [11] SUMEDANG
KECAMATAN : [181] SURIAN

Data Kemendagri			MFD 2021 Semester 2			
No	Kode	Nama Desa	No	Kode	Nama Desa	Status*
1	32.11.09.2001	WANASARI	1	3211181001	WANASARI	2
2	32.11.09.2002	WANAJAYA	2	3211181002	WANAJAYA	2
3	32.11.09.2003	PAMEKARSARI	3	3211181003	PAMEKARSARI	2
4	32.11.09.2004	SURIAN	4	3211181004	SURIAN	2
5	32.11.09.2005	TANJUNG	5	3211181005	TANJUNG	2
6	32.11.09.2006	RANGGASARI	6	3211181006	RANGGASARI	2
7	32.11.09.2007	SURIAMEDAL	7	3211181007	SURIAMEDAL	2
8	32.11.09.2008	SURIAMUKTI	8	3211181008	SURIAMUKTI	2
9	32.11.09.2009	NANJUNG-WANGI	9	3211181009	NANJUNG-WANGI	2

Catatan :
*) 1. Perkotaan
2. Perdesaan

https://jabar.bps.go.id

KABUPATEN INDRAMAYU

https://jabar.bps.go.id

https://jabar.bps.go.id

PROVINSI : [32] JAWA BARAT
KAB/KOTA : [12] INDRAMAYU

Data Kemendagri			MFD 2021 Semester 2		
No	Kode	Nama Kecamatan	No	Kode	Nama Kecamatan
1	32.12.01	HAURGEULIS	1	3212010	HAURGEULIS
2	32.12.25	GANTAR	2	3212011	GANTAR
3	32.12.02	KROYA	3	3212020	KROYA
4	32.12.03	GABUSWETAN	4	3212030	GABUSWETAN
5	32.12.04	CIKEDUNG	5	3212040	CIKEDUNG
6	32.12.26	TRISI	6	3212041	TERISI
7	32.12.05	LELEA	7	3212050	LELEA
8	32.12.06	BANGODUA	8	3212060	BANGODUA
9	32.12.30	TUKDANA	9	3212061	TUKDANA
10	32.12.07	WIDASARI	10	3212070	WIDASARI
11	32.12.08	KERTASEMAYA	11	3212080	KERTASEMAYA
12	32.12.27	SUKAGUMIWANG	12	3212081	SUKAGUMIWANG
13	32.12.09	KRANGKENG	13	3212090	KRANGKENG
14	32.12.10	KARANGAMPEL	14	3212100	KARANGAMPEL
15	32.12.28	KEDOKAN BUNDER	15	3212101	KEDOKANBUNDER
16	32.12.11	JUNTINYUAT	16	3212110	JUNTINYUAT
17	32.12.12	SLIYEG	17	3212120	SLIYEG
18	32.12.13	JATIBARANG	18	3212130	JATIBARANG
19	32.12.14	BALONGAN	19	3212140	BALONGAN
20	32.12.15	INDRAMAYU	20	3212150	INDRAMAYU
21	32.12.16	SINDANG	21	3212160	SINDANG
22	32.12.17	CANTIGI	22	3212161	CANTIGI
23	32.12.29	PASEKAN	23	3212162	PASEKAN
24	32.12.18	LOHBENER	24	3212170	LOHBENER
25	32.12.19	ARAHAN	25	3212171	ARAHAN

https://jabar.bps.go.id

DAFTAR KECAMATAN

PROVINSI : [32] JAWA BARAT
KAB/KOTA : [12] INDRAMAYU

Data Kemendagri			MFD 2021 Semester 2		
No	Kode	Nama Kecamatan	No	Kode	Nama Kecamatan
26	32.12.20	LOSARANG	26	3212180	LOSARANG
27	32.12.21	KANDANGHAUR	27	3212190	KANDANGHAUR
28	32.12.22	BONGAS	28	3212200	BONGAS
29	32.12.23	ANJATAN	29	3212210	ANJATAN
30	32.12.24	SUKRA	30	3212220	SUKRA
31	32.12.31	PATROL	31	3212221	PATROL

https://jabar.bps.go.id

JUMLAH DESA/KELURAHAN PER KECAMATAN

PROVINSI : [32] JAWA BARAT
KAB/KOTA : [12] INDRAMAYU

Data Kemendagri				MFD 2021 Semester 2			
No	Kode	Nama Kecamatan	Jml Desa	No	Kode	Nama Kecamatan	Jml Desa
1	32.12.01	HAURGEULIS	10	1	3212010	HAURGEULIS	10
2	32.12.25	GANTAR	7	2	3212011	GANTAR	7
3	32.12.02	KROYA	9	3	3212020	KROYA	9
4	32.12.03	GABUSWETAN	10	4	3212030	GABUSWETAN	10
5	32.12.04	CIKEDUNG	7	5	3212040	CIKEDUNG	7
6	32.12.26	TRISI	9	6	3212041	TERISI	9
7	32.12.05	LELEA	11	7	3212050	LELEA	11
8	32.12.06	BANGODUA	8	8	3212060	BANGODUA	8
9	32.12.30	TUKDANA	13	9	3212061	TUKDANA	13
10	32.12.07	WIDASARI	10	10	3212070	WIDASARI	10
11	32.12.08	KERTASEMAYA	13	11	3212080	KERTASEMAYA	13
12	32.12.27	SUKAGUMI-WANG	7	12	3212081	SUKAGUMI-WANG	7
13	32.12.09	KRANGKENG	11	13	3212090	KRANGKENG	11
14	32.12.10	KARANGAMPEL	11	14	3212100	KARANGAMPEL	11
15	32.12.28	KEDOKAN BUNDER	7	15	3212101	KEDOKANBUN-DER	7
16	32.12.11	JUNTINYUAT	12	16	3212110	JUNTINYUAT	12
17	32.12.12	SLIYEG	14	17	3212120	SLIYEG	14
18	32.12.13	JATIBARANG	15	18	3212130	JATIBARANG	15
19	32.12.14	BALONGAN	10	19	3212140	BALONGAN	10
20	32.12.15	INDRAMAYU	18	20	3212150	INDRAMAYU	18
21	32.12.16	SINDANG	10	21	3212160	SINDANG	10
22	32.12.17	CANTIGI	7	22	3212161	CANTIGI	7
23	32.12.29	PASEKAN	6	23	3212162	PASEKAN	6
24	32.12.18	LOHBENER	12	24	3212170	LOHBENER	12

https://jabar.bps.go.id

JUMLAH DESA/KELURAHAN PER KECAMATAN

PROVINSI : [32] JAWA BARAT
KAB/KOTA : [12] INDRAMAYU

Data Kemendagri				MFD 2021 Semester 2			
No	Kode	Nama Kecamatan	Jml Desa	No	Kode	Nama Kecamatan	Jml Desa
25	32.12.19	ARAHAN	8	25	3212171	ARAHAN	8
26	32.12.20	LOSARANG	12	26	3212180	LOSARANG	12
27	32.12.21	KANDANGHAUR	13	27	3212190	KANDANGHAUR	13
28	32.12.22	BONGAS	8	28	3212200	BONGAS	8
29	32.12.23	ANJATAN	13	29	3212210	ANJATAN	13
30	32.12.24	SUKRA	8	30	3212220	SUKRA	8
31	32.12.31	PATROL	8	31	3212221	PATROL	8

https://jabar.bps.go.id

PROVINSI : [32] JAWA BARAT
KAB/KOTA : [12] INDRAMAYU
KECAMATAN : [010] HAURGEULIS

Data Kemendagri			MFD 2021 Semester 2			
No	Kode	Nama Desa	No	Kode	Nama Desa	Status*
1	32.12.01.2007	HAURKOLOT	1	3212010007	HAURKOLOT	2
2	32.12.01.2008	HAURGEULIS	2	3212010008	HAURGEULIS	1
3	32.12.01.2009	SUKAJATI	3	3212010009	SUKAJATI	1
4	32.12.01.2010	WANAKAYA	4	3212010010	WANAKAYA	2
5	32.12.01.2011	KARANG TUMARITIS	5	3212010011	KARANG TUMARITIS	2
6	32.12.01.2012	KERTANEGARA	6	3212010012	KERTANEGARA	1
7	32.12.01.2013	CIPANCUH	7	3212010013	CIPANCUH	1
8	32.12.01.2014	MEKARJATI	8	3212010014	MEKARJATI	1
9	32.12.01.2015	SIDODADI	9	3212010015	SIDADADI	2
10	32.12.01.2016	SUMBER MULYA	10	3212010016	SUMBER MULYA	1

https://jabar.bps.go.id

Catatan :
*) 1. Perkotaan
2. Perdesaan

DAFTAR DESA/KELURAHAN

PROVINSI : [32] JAWA BARAT
KAB/KOTA : [12] INDRAMAYU
KECAMATAN : [011] GANTAR

Data Kemendagri			MFD 2021 Semester 2			
No	Kode	Nama Desa	No	Kode	Nama Desa	Status*
1	32.12.25.2001	BANTARWARU	1	3212011001	BANTARWARU	2
2	32.12.25.2002	SANCA	2	3212011002	SANCA	2
3	32.12.25.2003	MEKARJAYA	3	3212011003	MEKARJAYA	2
4	32.12.25.2004	GANTAR	4	3212011004	GANTAR	2
5	32.12.25.2005	SITURAJA	5	3212011005	SITURAJA	2
6	32.12.25.2006	BALEREJA	6	3212011006	BALERAJA	2
7	32.12.25.2007	MEKARWARU	7	3212011007	MEKARWARU	2

Catatan :
*) 1. Perkotaan
2. Perdesaan

https://jabar.bps.go.id

PROVINSI : [32] JAWA BARAT
KAB/KOTA : [12] INDRAMAYU
KECAMATAN : [020] KROYA

Data Kemendagri			MFD 2021 Semester 2			
No	Kode	Nama Desa	No	Kode	Nama Desa	Status*
1	32.12.02.2008	SUKA SLAMET	1	3210202001	SUKASLAMET	2
2	32.12.02.2001	TANJUNG KERTA	2	3210202002	TANJUNG KERTA	2
3	32.12.02.2002	KROYA	3	3210202003	KROYA	2
4	32.12.02.2003	SUMBON	4	3210202004	SUMBON	2
5	32.12.02.2004	SUKAMELANG	5	3210202005	SUKAMELANG	2
6	32.12.02.2005	TEMIYANG	6	3210202006	TEMIYANG	1
7	32.12.02.2006	TAMIYANGSARI	7	3210202007	TEMIYANGSARI	2
8	32.12.02.2007	JAYAMULYA	8	3210202008	JAYAMULYA	2
9	32.12.02.2009	SUMBERJAYA	9	3210202009	SUMBERJAYA	2

Catatan :
*) 1. Perkotaan
2. Perdesaan

https://jabar.bps.go.id

DAFTAR DESA/KELURAHAN

PROVINSI : [32] JAWA BARAT
KAB/KOTA : [12] INDRAMAYU
KECAMATAN : [030] GABUSWETAN

Data Kemendagri			MFD 2021 Semester 2			
No	Kode	Nama Desa	No	Kode	Nama Desa	Status*
1	32.12.03.2001	KEDUNGDAWA	1	3212030001	KEDUNGDAWA	2
2	32.12.03.2002	BABAKAN JAYA	2	3212030002	BABAKANJAYA	2
3	32.12.03.2003	GABUS KULON	3	3212030003	GABUSKULON	2
4	32.12.03.2004	SEKAR MULYA	4	3212030004	SEKARMULYA	2
5	32.12.03.2005	KEDOKAN GABUS	5	3212030005	KEDOKANGA-BUS	1
6	32.12.03.2006	RANCAMULYA	6	3212030006	RANCAMULYA	2
7	32.12.03.2007	RANCAHAN	7	3212030007	RANCAHAN	2
8	32.12.03.2008	GABUS WETAN	8	3212030008	GABUSWETAN	2
9	32.12.03.2009	DRUNTEN WETAN	9	3212030009	DRUNTEN WETAN	2
10	32.12.03.2010	DRUNTEN KULON	10	3212030010	DRUNTEN KULON	2

https://jabar.bps.go.id

Catatan :
*) 1. Perkotaan
2. Perdesaan

PROVINSI : [32] JAWA BARAT
KAB/KOTA : [12] INDRAMAYU
KECAMATAN : [040] CIKEDUNG

Data Kemendagri			MFD 2021 Semester 2			
No	Kode	Nama Desa	No	Kode	Nama Desa	Status*
1	32.12.04.2003	LOYANG	1	3212040003	LOYANG	2
2	32.12.04.2004	AMIS	2	3212040004	AMIS	2
3	32.12.04.2005	JATISURA	3	3212040005	JATISURA	2
4	32.12.04.2006	JAMBAK	4	3212040006	JAMBAK	2
5	32.12.04.2007	CIKEDUNG KIDUL	5	3212040007	CIKEDUNG	2
6	32.12.04.2012	CIKEDUNG LOR	6	3212040012	CIKEDUNG LOR	2
7	32.12.04.2013	MUNDAKJAYA	7	3212040013	MUNDAKJAYA	2

Catatan :
*) 1. Perkotaan
2. Perdesaan

https://jabar.bps.go.id

DAFTAR DESA/KELURAHAN

PROVINSI : [32] JAWA BARAT
KAB/KOTA : [12] INDRAMAYU
KECAMATAN : [041] TERISI

Data Kemendagri			MFD 2021 Semester 2			
No	Kode	Nama Desa	No	Kode	Nama Desa	Status*
1	32.12.26.2001	CIKAWUNG	1	3212041001	CIKAWUNG	2
2	32.12.26.2003	JATIMUNGGUL	2	3212041002	JATIMUNGGUL	2
3	32.12.26.2002	JATIMULYA	3	3212041003	JATIMULYA	2
4	32.12.26.2004	PLOSOKEREP	4	3212041004	PLOSOKEREP	2
5	32.12.26.2005	RAJASINGA	5	3212041005	RAJASINGA	1
6	32.12.26.2006	KARANGASEM	6	3212041006	KARANGASEM	1
7	32.12.26.2007	CIBERENG	7	3212041007	CIBERENG	1
8	32.12.26.2008	KENDAYAKAN	8	3212041008	KENDAYAKAN	2
9	32.12.26.2009	MANGGUN-GAN	9	3212041009	MANGGUN-GAN	2

Catatan :
*) 1. Perkotaan
2. Perdesaan

https://jabar.bps.go.id

PROVINSI : [32] JAWA BARAT
KAB/KOTA : [12] INDRAMAYU
KECAMATAN : [050] LELEA

Data Kemendagri			MFD 2021 Semester 2			
No	Kode	Nama Desa	No	Kode	Nama Desa	Status*
1	32.12.05.2001	TUNGGUL-PAYUNG	1	3212050001	TUNGGUL PAYUNG	1
2	32.12.05.2002	TUGU	2	3212050002	TUGU	1
3	32.12.05.2003	NUNUK	3	3212050003	NUNUK	2
4	32.12.05.2004	TEMPEL	4	3212050004	TEMPEL	2
5	32.12.05.2005	PANGAUBAN	5	3212050005	PANGAUBAN	2
6	32.12.05.2006	TEGALASARI	6	3212050006	TEGALASARI	2
7	32.12.05.2007	LANGGENG-SARI	7	3212050007	LANGGENG-SARI	2
8	32.12.05.2008	TAMANSARI	8	3212050008	TAMANSARI	1
9	32.12.05.2009	LELEA	9	3212050009	LELEA	1
10	32.12.05.2010	CEMPEH	10	3212050010	CEMPEH	2
11	32.12.05.2011	TEMPELKULON	11	3212050011	TEMPELKULON	2

Catatan :
*) 1. Perkotaan
2. Perdesaan

https://jabar.bps.go.id

DAFTAR DESA/KELURAHAN

PROVINSI : [32] JAWA BARAT
KAB/KOTA : [12] INDRAMAYU
KECAMATAN : [060] BANGODUA

Data Kemendagri			MFD 2021 Semester 2			
No	Kode	Nama Desa	No	Kode	Nama Desa	Status*
1	32.12.06.2008	MULYASARI	1	3212060008	MULYASARI	2
2	32.12.06.2015	BANGODUA	2	3212060015	BANGODUA	2
3	32.12.06.2016	BEDUYUT	3	3212060016	BEDUYUT	2
4	32.12.06.2019	KARANGGETAS	4	3212060017	KARANGGETAS	2
5	32.12.06.2020	TEGALGIRANG	5	3212060018	TEGALGIRANG	2
6	32.12.06.2018	WANASARI	6	3212060019	WANASARI	2
7	32.12.06.2021	MALANGSARI	7	3212060020	MALANGSARI	2
8	32.12.06.2017	RANCASARI	8	3212060021	RANCASARI	2

Catatan :
*) 1. Perkotaan
2. Perdesaan

https://jabar.bps.go.id

PROVINSI : [32] JAWA BARAT
KAB/KOTA : [12] INDRAMAYU
KECAMATAN : [061] TUKDANA

Data Kemendagri			MFD 2021 Semester 2			
No	Kode	Nama Desa	No	Kode	Nama Desa	Status*
1	32.12.30.2001	BODAS	1	3212061001	BODAS	2
2	32.12.30.2002	GADEL	2	3212061002	GADEL	2
3	32.12.30.2003	RANCAJAWAT	3	3212061003	RANCAJAWAT	2
4	32.12.30.2004	KERTICALA	4	3212061004	KERTICALA	2
5	32.12.30.2007	SUKAMULYA	5	3212061005	SUKAMULYA	2
6	32.12.30.2006	KARANGKERTA	6	3212061006	KARANGKERTA	1
7	32.12.30.2005	CANGKO	7	3212061007	CANGKO	2
8	32.12.30.2012	PAGEDANGAN	8	3212061008	PAGEDANGAN	2
9	32.12.30.2013	SUKAPERNA	9	3212061009	SUKAPERNA	2
10	32.12.30.2011	SUKADANA	10	3212061010	SUKADANA	2
11	32.12.30.2010	TUKDANA	11	3212061011	TUKDANA	2
12	32.12.30.2009	LAJER	12	3212061012	LAJER	1
13	32.12.30.2008	MEKARSARI	13	3212061013	MEKARSARI	2

Catatan :
*) 1. Perkotaan
2. Perdesaan

https://jabar.bps.go.id

DAFTAR DESA/KELURAHAN

PROVINSI : [32] JAWA BARAT
KAB/KOTA : [12] INDRAMAYU
KECAMATAN : [070] WIDASARI

Data Kemendagri			MFD 2021 Semester 2			
No	Kode	Nama Desa	No	Kode	Nama Desa	Status*
1	32.12.07.2006	BANGKALOA ILIR	1	3212070006	BANGKALOA ILIR	2
2	32.12.07.2007	WIDASARI	2	3212070007	WIDASARI	1
3	32.12.07.2008	KALENSARI	3	3212070008	KALENSARI	2
4	32.12.07.2010	BUNDER	4	3212070010	BUNDER	2
5	32.12.07.2011	UJUNGARIS	5	3212070011	UJUNGARIS	2
6	32.12.07.2012	KONGSIJAYA	6	3212070012	KONGSIJAYA	1
7	32.12.07.2013	UJUNGJAYA	7	3212070013	UJUNGJAYA	2
8	32.12.07.2014	UJUNGPEN-DOK JAYA	8	3212070014	UJUNGPEN-DOK JAYA	2
9	32.12.07.2015	LEUWIGEDE	9	3212070015	LEUWIGEDE	2
10	32.12.07.2016	KASMARAN	10	3212070016	KASMARAN	2

Catatan :
*) 1. Perkotaan
2. Perdesaan

https://jabar.bps.go.id

PROVINSI : [32] JAWA BARAT
KAB/KOTA : [12] INDRAMAYU
KECAMATAN : [080] KERTASEMAYA

Data Kemendagri			MFD 2021 Semester 2			
No	Kode	Nama Desa	No	Kode	Nama Desa	Status*
1	32.12.08.2007	TULUNG AGUNG	1	3212080007	TULUNG AGUNG	1
2	32.12.08.2008	JENGKOK	2	3212080008	JENGKOK	2
3	32.12.08.2009	TEGAL WIRANGRONG	3	3212080009	TEGAL WIRANGRONG	2
4	32.12.08.2010	MANGUNTARA	4	3212080010	MANGUNTARA	2
5	32.12.08.2011	JAMBE	5	3212080011	JAMBE	2
6	32.12.08.2012	LEMAHAYU	6	3212080012	LEMAHAYU	2
7	32.12.08.2013	TENAJAR KIDUL	7	3212080013	TENAJAR KIDUL	2
8	32.12.08.2014	KERTASEMAYA	8	3212080014	KERTASEMAYA	1
9	32.12.08.2015	KLIWED	9	3212080015	KLIWED	2
10	32.12.08.2016	TENAJAR	10	3212080016	TENAJAR	2
11	32.12.08.2017	LARANGAN JAMBE	11	3212080017	LARANGAN-JAMBE	2
12	32.12.08.2018	TENAJAR LOR	12	3212080018	TENAJAR LOR	2
13	32.12.08.2019	SUKAWERA	13	3212080019	SUKAWERA	2

Catatan :
*) 1. Perkotaan
2. Perdesaan

https://jabar.bps.go.id

DAFTAR DESA/KELURAHAN

PROVINSI : [32] JAWA BARAT
KAB/KOTA : [12] INDRAMAYU
KECAMATAN : [081] SUKAGUMIWANG

Data Kemendagri			MFD 2021 Semester 2			
No	Kode	Nama Desa	No	Kode	Nama Desa	Status*
1	32.12.27.2001	CIBEBER	1	3212081001	CIBEBER	2
2	32.12.27.2002	BONDAN	2	3212081002	BONDAN	2
3	32.12.27.2003	GUNUNGSARI	3	3212081003	GUNUNGSARI	2
4	32.12.27.2004	SUKAGUMI-WANG	4	3212081004	SUKAGUMI-WANG	2
5	32.12.27.2005	TERSANA	5	3212081005	TERSANA	2
6	32.12.27.2006	CADANG PING-GAN	6	3212081006	CADANGPING-GAN	2
7	32.12.27.2007	GEDANGAN	7	3212081007	GEDANGAN	2

Catatan :
*) 1. Perkotaan
2. Perdesaan

https://jabar.bps.go.id

PROVINSI : [32] JAWA BARAT
KAB/KOTA : [12] INDRAMAYU
KECAMATAN : [090] KRANGKENG

Data Kemendagri			MFD 2021 Semester 2			
No	Kode	Nama Desa	No	Kode	Nama Desa	Status*
1	32.12.09.2001	PURWAJAYA	1	3212090001	PURWAJAYA	2
2	32.12.09.2002	KAPRINGAN	2	3212090002	KAPRINGAN	2
3	32.12.09.2003	SINGAKERTA	3	3212090003	SINGAKERTA	2
4	32.12.09.2004	DUKUHJATI	4	3212090004	DUKUHJATI	1
5	32.12.09.2005	TEGALMULYA	5	3212090005	TEGALMULYA	2
6	32.12.09.2006	KEDUNG WUNGU	6	3212090006	KEDUNG WUNGU	2
7	32.12.09.2007	SRENGSENG	7	3212090007	SRENGSENG	2
8	32.12.09.2008	LUWUNGGESIK	8	3212090008	LUWUNGGESIK	2
9	32.12.09.2009	KALIANYAR	9	3212090009	KALIANYAR	2
10	32.12.09.2010	KRANGKENG	10	3212090010	KRANGKENG	2
11	32.12.09.2011	TANJAKAN	11	3212090011	TANJAKAN	2

Catatan :
*) 1. Perkotaan
2. Perdesaan

https://jabar.bps.go.id

DAFTAR DESA/KELURAHAN

PROVINSI : [32] JAWA BARAT
KAB/KOTA : [12] INDRAMAYU
KECAMATAN : [100] KARANGAMPEL

Data Kemendagri			MFD 2021 Semester 2			
No	Kode	Nama Desa	No	Kode	Nama Desa	Status*
1	32.12.10.2019	KAPLONGAN LOR	1	3212110001	KAPLONGAN-LOR	2
2	32.12.10.2008	TANJUNGPURA	2	3212110002	TANJUNGPURA	2
3	32.12.10.2009	TANJUNGSARI	3	3212110003	TANJUNGSARI	1
4	32.12.10.2010	PRINGGACALA	4	3212110004	PRINGGACALA	1
5	32.12.10.2011	BENDA	5	3212110005	BENDA	1
6	32.12.10.2012	SENDANG	6	3212110006	SENDANG	1
7	32.12.10.2013	KARANGAM-PEL KIDUL	7	3212110007	KARANGAM-PEL KIDUL	1
8	32.12.10.2014	KARANGAM-PEL	8	3212110008	KARANGAM-PEL	1
9	32.12.10.2015	DUKUH JERUK	9	3212110009	DUKUHJERUK	1
10	32.12.10.2016	DUKUH TENGAH	10	3212110010	DUKUH TENGAH	1
11	32.12.10.2017	MUNDU	11	3212110011	MUNDU	1

Catatan :
*) 1. Perkotaan
2. Perdesaan

https://jabar.bps.go.id

PROVINSI : [32] JAWA BARAT
KAB/KOTA : [12] INDRAMAYU
KECAMATAN : [101] KEDOKAN BUNDER

Data Kemendagri			MFD 2021 Semester 2			
No	Kode	Nama Desa	No	Kode	Nama Desa	Status*
1	32.12.28.2005	KEDOKANBUN-DERWETAN	1	3212101001	KEDOKANBUN-DER WETAN	2
2	32.12.28.2006	KAPLONGAN	2	3212101002	KAPLONGAN	2
3	32.12.28.2003	KEDOKAN AGUNG	3	3212101003	KEDOKAN AGUNG	2
4	32.12.28.2004	KEDOKANBUN-DER	4	3212101004	KEDOKANBUN-DER	1
5	32.12.28.2002	JAYAWINANG UN	5	3212101005	JAYAWINANG UN	2
6	32.12.28.2001	CANGKINGAN	6	3212101006	CANGKINGAN	2
7	32.12.28.2007	JAYALAKSANA	7	3212101007	JAYALAKSANA	2

Catatan :
*) 1. Perkotaan
2. Perdesaan

https://jabar.bps.go.id

DAFTAR DESA/KELURAHAN

PROVINSI : [32] JAWA BARAT
KAB/KOTA : [12] INDRAMAYU
KECAMATAN : [110] JUNTINYUAT

Data Kemendagri			MFD 2021 Semester 2			
No	Kode	Nama Desa	No	Kode	Nama Desa	Status*
1	32.12.11.2001	SEGERAN KIDUL	1	3212110001	SEGERAN KIDUL	2
2	32.12.11.2002	SEGERAN	2	3212110002	SEGERAN	1
3	32.12.11.2003	JUNTIWEDEN	3	3212110003	JUNTIWEDEN	2
4	32.12.11.2010	JUNYIKEBON	4	3212110004	JUNYIKEBON	1
5	32.12.11.2004	DADAP	5	3212110005	DADAP	1
6	32.12.11.2005	JUNTINYUAT	6	3212110006	JUNTINYUAT	1
7	32.12.11.2006	JUNTIKEDOKAN	7	3212110007	JUNTIKEDOKAN	2
8	32.12.11.2007	PONDOH	8	3212110008	PONDOH	2
9	32.12.11.2008	SAMBIMAYA	9	3212110009	SAMBIMAYA	2
10	32.12.11.2009	TINUMPUK	10	3212110010	TINUMPUK	2
11	32.12.11.2011	LOMBANG	11	3212110011	LOMBANG	2
12	32.12.11.2012	LIMBANGAN	12	3212110012	LIMBANGAN	2

Catatan :
*) 1. Perkotaan
2. Perdesaan

https://jabar.bps.go.id

PROVINSI : [32] JAWA BARAT
KAB/KOTA : [12] INDRAMAYU
KECAMATAN : [120] SLIYEG

Data Kemendagri			MFD 2021 Semester 2			
No	Kode	Nama Desa	No	Kode	Nama Desa	Status*
1	32.12.12.2001	SLEMAN	1	3212110001	SLEMAN	2
2	32.12.12.2002	TAMBI	2	3212110002	TAMBI	2
3	32.12.12.2003	SUDIKAMPI-RAN	3	3212110003	SUDIKAMPI-RAN	2
4	32.12.12.2004	TAMBI LOR	4	3212110004	TAMBI LOR	2
5	32.12.12.2005	SLEMAN LOR	5	3212110005	SLEMAN LOR	1
6	32.12.12.2006	MAJASARI	6	3212110006	MAJASARI	2
7	32.12.12.2007	MAJASIH	7	3212110007	MAJASIH	2
8	32.12.12.2008	SLIYEG	8	3212110008	SLIYEG	2
9	32.12.12.2009	GADINGAN	9	3212110009	GADINGAN	1
10	32.12.12.2010	MEKAR GADING	10	3212110010	MEKAR GADING	2
11	32.12.12.2011	SLIYEG LOR	11	3212110011	SLIYEGLOR	2
12	32.12.12.2012	TUGU KIDUL	12	3212110012	TUGUKIDUL	2
13	32.12.12.2013	TUGU	13	3212110013	TUGU	2
14	32.12.12.2016	LONGOK	14	3212110013	LONGOK	2

Catatan :
*) 1. Perkotaan
2. Perdesaan

https://jabar.bps.go.id

DAFTAR DESA/KELURAHAN

PROVINSI : [32] JAWA BARAT
KAB/KOTA : [12] INDRAMAYU
KECAMATAN : [130] JATIBARANG

Data Kemendagri			MFD 2021 Semester 2			
No	Kode	Nama Desa	No	Kode	Nama Desa	Status*
1	32.12.13.2001	SUKALILA	1	3212110001	SUKALILA	2
2	32.12.13.2002	PILANGSARI	2	3212110002	PILANGSARI	1
3	32.12.13.2003	JATIBARANG BARU	3	3212110003	JATIBARANG BARU	1
4	32.12.13.2004	BULAK	4	3212110004	BULAK	1
5	32.12.13.2005	BULAK LOR	5	3212110005	BULAK LOR	1
6	32.12.13.2006	JATIBARANG	6	3212110006	JATIBARANG	1
7	32.12.13.2007	KEBULEN	7	3212110007	KEBULEN	1
8	32.12.13.2008	PAWIDEAN	8	3212110008	PAWIDEAN	2
9	32.12.13.2009	JATISAWIT	9	3212110009	JATISAWIT	2
10	32.12.13.2010	JATISAWIT LOR	10	3212110010	JATISAWIT LOR	2
11	32.12.13.2011	KRASAK	11	3212110011	KRASAK	2
12	32.12.13.2012	KALIMATI	12	3212110012	KALIMATI	2
13	32.12.13.2013	MALANG SEMI-RANG	13	3212110013	MALANGSEMI-RANG	2
14	32.12.13.2014	LOHBENER	14	3212110013	LOHBENER	2
15	32.12.13.2015	LOHBENER LOR	15	3212110014	LOHBENER LOR	2

Catatan :
*) 1. Perkotaan
2. Perdesaan

https://jabar.bps.go.id

PROVINSI : [32] JAWA BARAT
KAB/KOTA : [12] INDRAMAYU
KECAMATAN : [140] BALONGAN

Data Kemendagri			MFD 2021 Semester 2			
No	Kode	Nama Desa	No	Kode	Nama Desa	Status*
1	32.12.14.2001	TEGAL SEM-BADRA	1	3212140001	TEGAL SEM-BADRA	1
2	32.12.14.2002	SUKAREJA	2	3212140002	SUKAREJA	2
3	32.12.14.2003	SUKAURIP	3	3212140003	SUKAURIP	1
4	32.12.14.2004	RAWADALEM	4	3212140004	RAWADALEM	2
5	32.12.14.2005	GELARMEN-DALA	5	3212140005	GELARMEN-DALA	2
6	32.12.14.2006	TEGALURUNG	6	3212140006	TEGALURUNG	1
7	32.12.14.2007	BALONGAN	7	3212140007	BALONGAN	1
8	32.12.14.2009	SUDIMAMPIR	8	3212140008	SUDIMAMPIR	1
9	32.12.14.2010	SUDIMAMPIR LOR	9	3212140009	SUDIMAMPIR LOR	2
10	32.12.14.2008	MAJAKERTA	10	3212140010	MAJAKERTA	2

Catatan :
*) 1. Perkotaan
2. Perdesaan

https://jabar.bps.go.id

DAFTAR DESA/KELURAHAN

PROVINSI : [32] JAWA BARAT
KAB/KOTA : [12] INDRAMAYU
KECAMATAN : [150] INDRAMAYU

Data Kemendagri			MFD 2021 Semester 2			
No	Kode	Nama Desa	No	Kode	Nama Desa	Status*
1	32.12.15.2009	TELUKAGUNG	1	3212150001	TELUKAGUNG	2
2	32.12.15.2010	PLUMBON	2	3212150002	PLUMBON	2
3	32.12.15.2011	DUKUH	3	3212150003	DUKUH	1
4	32.12.15.2012	PEKANDAN-GAN JAYA	4	3212150004	PEKANDAN-GAN JAYA	1
5	32.12.15.2013	SINGARAJA	5	3212150005	SINGARAJA	1
6	32.12.15.2014	SINGAJAYA	6	3212150006	SINGAJAYA	1
7	32.12.15.2015	PEKANDAN-GAN	7	3212150007	PEKANDAN-GAN	1
8	32.12.15.1001	BOJONGSARI	8	3212150008	BOJONGSARI	1
9	32.12.15.1002	KEPANDEAN	9	3212150009	KEPANDEAN	1
10	32.12.15.1003	KARANG-MALANG	10	3212150010	KARANG-MALANG	1
11	32.12.15.1004	KARANG ANYAR	11	3212150011	KARANG ANYAR	1
12	32.12.15.1005	LEMAHMEKAR	12	3212150012	LEMAHMEKAR	1
13	32.12.15.1006	LEMAHABANG	13	3212150013	LEMAHABANG	1
14	32.12.15.1007	MARGADADI	14	3212150014	MARGADADI	1
15	32.12.15.1008	PAOMAN	15	3212150015	PAOMAN	1
16	32.12.15.2016	KARANGSONG	16	3212150016	KARANGSONG	1
17	32.12.15.2017	PABEAN UDIK	17	3212150017	PABEANUDIK	1
18	32.12.15.2020	TAMBAK	18	3212150018	TAMBAK	1

Catatan :
*) 1. Perkotaan
2. Perdesaan

https://jabar.bps.go.id

PROVINSI : [32] JAWA BARAT
KAB/KOTA : [12] INDRAMAYU
KECAMATAN : [160] SINDANG

Data Kemendagri			MFD 2021 Semester 2			
No	Kode	Nama Desa	No	Kode	Nama Desa	Status*
1	32.12.16.2001	PANYINDANGAN KULON	1	3212160007	PANYINDANGAN KULON	2
2	32.12.16.2002	RAMBATAN WETAN	2	3212160008	RAMBATAN WETAN	1
3	32.12.16.2003	PANYINDANGAN WETAN	3	3212160009	PANYINDANGAN WETAN	1
4	32.12.16.2004	KENANGA	4	3212160010	KENANGA	1
5	32.12.16.2005	TERUSAN	5	3212160011	TERUSAN	1
6	32.12.16.2006	DERMAYU	6	3212160012	DERMAYU	1
7	32.12.16.2007	SINDANG	7	3212160013	SINDANG	1
8	32.12.16.2008	PENGANJANG	8	3212160014	PENGANJANG	1
9	32.12.16.2009	BABADAN	9	3212160015	BABADAN	2
10	32.12.16.2014	WANANTARA	10	3212160016	WANANTARA	2

Catatan :
*) 1. Perkotaan
2. Perdesaan

https://jabar.bps.go.id

DAFTAR DESA/KELURAHAN

PROVINSI : [32] JAWA BARAT
KAB/KOTA : [12] INDRAMAYU
KECAMATAN : [161] CANTIGI

Data Kemendagri			MFD 2021 Semester 2			
No	Kode	Nama Desa	No	Kode	Nama Desa	Status*
1	32.12.17.2001	CANGKRING	1	3212161001	CANGKRING	2
2	32.12.17.2002	CANTIGI KULON	2	3212161002	CANTIGI KULON	2
3	32.12.17.2003	CANTIGI WETAN	3	3212161003	CANTIGI WETAN	1
4	32.12.17.2005	PANYINGKIRAN LOR	4	3212161004	PANYINGKIRAN LOR	2
5	32.12.17.2004	PANYINGKIRAN KIDUL	5	3212161005	PANYINGKIRAN KIDUL	2
6	32.12.17.2006	LAMARANTA-RUNG	6	3212161006	LAMARANTA-RUNG	2
7	32.12.17.2007	CEMARA	7	3212161007	CEMARA	2

Catatan :
*) 1. Perkotaan
2. Perdesaan

https://jabar.bps.go.id

PROVINSI : [32] JAWA BARAT
KAB/KOTA : [12] INDRAMAYU
KECAMATAN : [162] PASEKAN

Data Kemendagri			MFD 2021 Semester 2			
No	Kode	Nama Desa	No	Kode	Nama Desa	Status*
1	32.12.29.2003	PAGIRIKAN	1	3212162001	PAGIRIKAN	2
2	32.12.29.2004	PASEKAN	2	3212162002	PASEKAN	2
3	32.12.29.2001	BRONDONG	3	3212162003	BRONDONG	2
4	32.12.29.2002	PABEAN ILIR	4	3212162004	PABEANILIR	2
5	32.12.29.2006	TOTORAN	5	3212162005	TOTORAN	2
6	32.12.29.2005	KARANG ANYAR	6	3212162006	KARANG ANYAR	2

Catatan :
*) 1. Perkotaan
2. Perdesaan

https://jabar.bps.go.id

DAFTAR DESA/KELURAHAN

PROVINSI : [32] JAWA BARAT
KAB/KOTA : [12] INDRAMAYU
KECAMATAN : [170] LOHBENER

Data Kemendagri			MFD 2021 Semester 2			
No	Kode	Nama Desa	No	Kode	Nama Desa	Status*
1	32.12.18.2002	KIAJARAN KULON	1	3212170001	KIAJARAN KULON	2
2	32.12.18.2001	KIAJARAN WETAN	2	3212170002	KIJARAN WETAN	2
3	32.12.18.2003	LANJAN	3	3212170003	LANJAN	2
4	32.12.18.2004	LANGUT	4	3212170004	LANGUT	2
5	32.12.18.2005	LARANGAN	5	3212170005	LARANGAN	2
6	32.12.18.2006	WARU	6	3212170006	WARU	2
7	32.12.18.2007	LEGOK	7	3212170007	LEGOK	2
8	32.12.18.2008	BOJONGSLAWI	8	3212170008	BOJONGSLAWI	2
9	32.12.18.2009	LOHBENER	9	3212170009	LOHBENER	1
10	32.12.18.2010	PAMAYAHAN	10	3212170010	PAMAYAHAN	1
11	32.12.18.2011	SINDANGKER-TA	11	3212170011	SINDANGKER-TA	1
12	32.12.18.2012	RAMBATANKU-LON	12	3212170012	RAMBATANKU-LON	1

Catatan :
*) 1. Perkotaan
2. Perdesaan

https://jabar.bps.go.id

PROVINSI : [32] JAWA BARAT
KAB/KOTA : [12] INDRAMAYU
KECAMATAN : [171] ARAHAN

Data Kemendagri			MFD 2021 Semester 2			
No	Kode	Nama Desa	No	Kode	Nama Desa	Status
1	32.12.19.2007	SUKASARI	1	3212171001	SUKASARI	2
2	32.12.19.2001	ARAHAN KIDUL	2	3212171002	ARAHAN KIDUL	2
3	32.12.19.2002	ARAHAN LOR	3	3212171003	ARAHAN LOR	2
4	32.12.19.2003	LINGGAJATI	4	3212171004	LINGGAJATI	2
5	32.12.19.2008	TAWANGSARI	5	3212171005	TAWANGSARI	2
6	32.12.19.2005	SUKADADI	6	3212171006	SUKADADI	2
7	32.12.19.2006	PRANGGONG	7	3212171007	PRANGGONG	2
8	32.12.19.2004	CIDEMPET	8	3212171008	CIDEMPET	2

Catatan :
*) 1. Perkotaan
2. Perdesaan

https://jabar.bps.go.id

DAFTAR DESA/KELURAHAN

PROVINSI : [32] JAWA BARAT
KAB/KOTA : [12] INDRAMAYU
KECAMATAN : [180] LOSARANG

Data Kemendagri			MFD 2021 Semester 2			
No	Kode	Nama Desa	No	Kode	Nama Desa	Status
1	32.12.20.2001	RANJENG	1	321280001	RANJENG	2
2	32.12.20.2002	KRIMUN	2	321280002	KRIMUN	1
3	32.12.20.2003	PUNTANG	3	321280003	PUNTANG	1
4	32.12.20.2004	PEGAGAN	4	321280004	PEGAGAN	2
5	32.12.20.2005	RAJAIYANG	5	321280005	RAJAIYANG	2
6	32.12.20.2006	JANGGA	6	321280006	JANGGA	1
7	32.12.20.2007	JUMBLENG	7	321280007	JUMBLENG	2
8	32.12.20.2008	PANGKALAN	8	321280008	PANGKALAN	2
10	32.12.20.2010	LOSARANG	10	321280010	LOSARANG	2
11	32.12.20.2011	MUNTUR	11	321280011	MUNTUR	1
12	32.12.20.2012	SANTING	12	321280012	SANTING	1
13	32.12.20.2013	CEMARA KULON	13	321280013	CEMARA KULON	2

Catatan :
*) 1. Perkotaan
2. Perdesaan

https://jabar.bps.go.id

PROVINSI : [32] JAWA BARAT
KAB/KOTA : [12] INDRAMAYU
KECAMATAN : [190] KANDANGHAUR

Data Kemendagri			MFD 2021 Semester 2			
No	Kode	Nama Desa	No	Kode	Nama Desa	Status*
1	32.12.21.2001	CURUG	1	3212190001	CURUG	2
2	32.12.21.2002	PRANTI	2	3212190002	PRANTI	2
3	32.12.21.2003	WIRAKANAN	3	3212190003	WIRAKANAN	2
4	32.12.21.2004	KARANG MULYA	4	3212190004	KARANG MULYA	1
5	32.12.21.2005	KARANG ANYAR	5	3212190005	KARANG ANYAR	1
6	32.12.21.2006	WIRAPANJU-NAN	6	3212190006	WIRAPANJU-NAN	1
7	32.12.21.2007	PAREANGI-RANG	7	3212190007	PAREAN GI-RANG	1
8	32.12.21.2008	BULAK	8	3212190008	BULAK	2
9	32.12.21.2009	ILIR	9	3212190009	ILIR	1
10	32.12.21.2010	SOGE	10	3212190010	SOGE	2
11	32.12.21.2011	ERETAN WETAN	11	3212190011	ERETAN WETAN	1
12	32.12.21.2012	ERETAN KU-LON	12	3212190012	ERETAN KU-LON	1
13	32.12.21.2013	KERTAWINANG UN	12	3212190013	KERTAWINANG UN	1

Catatan :
*) 1. Perkotaan
2. Perdesaan

https://jabar.bps.go.id

DAFTAR DESA/KELURAHAN

PROVINSI : [32] JAWA BARAT
KAB/KOTA : [12] INDRAMAYU
KECAMATAN : [200] BONGAS

Data Kemendagri			MFD 2021 Semester 2			
No	Kode	Nama Desa	No	Kode	Nama Desa	Status*
1	32.12.22.2001	CIPEDANG	1	3212200001	CIPEDANG	2
2	32.12.22.2002	SIDAMULYA	2	3212200002	SIDAMULYA	2
3	32.12.22.2003	MARGAMULYA	3	3212200003	MARGAMULYA	1
4	32.12.22.2004	KERTAJAYA	4	3212200004	KERTAJAYA	1
5	32.12.22.2005	BONGAS	5	3212200005	BONGAS	2
6	32.12.22.2006	CIPAAT	6	3212200006	CIPAAT	2
7	32.12.22.2007	KRETAMULYA	7	3212200007	KRETAMULYA	1
8	32.12.22.2008	PLAWANGAN	8	3212200008	PLAWANGAN	2

Catatan :
*) 1. Perkotaan
2. Perdesaan

https://jabar.bps.go.id

PROVINSI : [32] JAWA BARAT
KAB/KOTA : [12] INDRAMAYU
KECAMATAN : [210] ANJATAN

Data Kemendagri			MFD 2021 Semester 2			
No	Kode	Nama Desa	No	Kode	Nama Desa	Status*
1	32.12.23.2002	MANGUNJAYA	1	3212210001	MANGUNJAYA	2
2	32.12.23.2004	BUGIS TUA	2	3212210002	BUGISTUA	2
3	32.12.23.2003	BUGIS	3	3212210003	BUGIS	2
4	32.12.23.2005	SALAMDARMA	4	3212210004	SALAMDARMA	2
5	32.12.23.2006	KEDUNGWUN-GU	5	3212210005	KEDUNGWUN-GU	1
6	32.12.23.2007	WANGUK	6	3212210006	WANGUK	2
7	32.12.23.2008	LEMPUYANG	7	3212210007	LEMPUYANG	2
8	32.12.23.2009	KOPYAH	8	3212210008	KOPYAH	2
9	32.12.23.2010	ANJATAN BARU	9	3212210009	ANJATAN BARU	1
10	32.12.23.2001	ANJATAN	10	3212210010	ANJATAN	1
11	32.12.23.2011	CILANDAK	11	3212210011	CILANDAK	2
12	32.12.23.2012	CILANDAK LOR	12	3212210012	CILANDAK LOR	2
13	32.12.23.2013	ANJATAN UTARA	12	3212210013	ANJATAN UTARA	1

Catatan :
*) 1. Perkotaan
2. Perdesaan

https://jabar.bps.go.id

DAFTAR DESA/KELURAHAN

PROVINSI : [32] JAWA BARAT
KAB/KOTA : [12] INDRAMAYU
KECAMATAN : [220] SUKRA

Data Kemendagri			MFD 2021 Semester 2			
No	Kode	Nama Desa	No	Kode	Nama Desa	Status*
1	32.12.24.2001	BOGOR	1	3212220001	BOGOR	1
2	32.12.24.2002	SUKRA	2	3212220002	SUKRA	1
3	32.12.24.2003	UJUNGGE-BANG	3	3212220003	UJUNGGE-BANG	2
4	32.12.24.2004	TAGAL TAMAN	4	3212220004	TEGALTAMAN	2
5	32.12.24.2005	SUKRAWETAN	5	3212220005	SUKRAWETAN	1
6	32.12.24.2006	SUMURADEM	6	3212220006	SUMURADEM	1
7	32.12.24.2007	SUMURADEM-TIMUR	7	3212220007	SUMURADEM-TIMUR	1
8	32.12.24.2017	KARANG LAYUNG	8	3212220008	KARAN-GLAYUNG	1

Catatan :
*) 1. Perkotaan
2. Perdesaan

https://jabar.bps.go.id

PROVINSI : [32] JAWA BARAT
KAB/KOTA : [12] INDRAMAYU
KECAMATAN : [221] PATROL

Data Kemendagri			MFD 2021 Semester 2			
No	Kode	Nama Desa	No	Kode	Nama Desa	Status*
1	32.12.31.2001	LIMPAS	1	3212221001	LIMPAS	1
2	32.12.31.2005	PATROL	2	3212221002	PATROL	1
3	32.12.31.2007	ARJASARI	3	3212221003	ARJASARI	2
4	32.12.31.2008	SUKAHAJI	4	3212221004	SUKAHAJI	1
5	32.12.31.2006	BUGEL	5	3212221005	BUGEL	1
6	32.12.31.2004	PATROLLOR	6	3212221006	PATROLLOR	1
7	32.12.31.2003	PATROL BARU	7	3212221007	PATROL BARU	1
8	32.12.31.2002	MEKARSARI	8	3212221008	MEKARSARI	2

Catatan :
*) 1. Perkotaan
2. Perdesaan

https://jabar.bps.go.id

https://jabar.bps.go.id

KABUPATEN SUBANG

https://jabar.bps.go.id

https://jabar.bps.go.id

PROVINSI : [32] JAWA BARAT
KAB/KOTA : [13] SUBANG

Data Kemendagri			MFD 2021 Semester 2		
No	Kode	Nama Kecamatan	No	Kode	Nama Kecamatan
1	32.13.01	SAGALAHERANG	1	3213010	SAGALAHERANG
2	32.13.23	SERANGPANJANG	2	3213011	SERANGPANJANG
3	32.13.12	JALANCAGAK	3	3213020	JALANCAGAK
4	32.13.29	CIATER	4	3213021	CIATER
5	32.13.02	CISALAK	5	3213030	CISALAK
6	32.13.26	KASOMALANG	6	3213031	KASOMALANG
7	32.13.14	TANJUNGSIANG	7	3213040	TANJUNGSIANG
8	32.13.19	CIJAMBE	8	3213050	CIJAMBE
9	32.13.17	CIBOGO	9	3213060	CIBOGO
10	32.13.03	SUBANG	10	3213070	SUBANG
11	32.13.04	KALIJATI	11	3213080	KALIJATI
12	32.13.27	DAWUAN	12	3213081	DAWUAN
13	32.13.20	CIPEUNDEUY	13	3213090	CIPEUNDEUY
14	32.13.05	PABUARAN	14	3213100	PABUARAN
15	32.13.16	PATOKBEUSI	15	3213110	PATOKBEUSI
16	32.13.06	PURWADADI	16	3213120	PURWADADI
17	32.13.22	CIKAUM	17	3213130	CIKAUM
18	32.13.07	PAGADEN	18	3213140	PAGADEN
19	32.13.28	PAGADEN BARAT	19	3213141	PAGADEN BARAT
20	32.13.18	CIPUNAGARA	20	3213150	CIPUNAGARA
21	32.13.15	COMPRENG	21	3213160	COMPRENG
22	32.13.08	BINONG	22	3213170	BINONG
23	32.13.25	TAMBAKDAHAN	23	3213171	TAMBAKDAHAN
24	32.13.09	CIASEM	24	3213180	CIASEM

https://jabar.bps.go.id

DAFTAR KECAMATAN

PROVINSI : [32] JAWA BARAT
KAB/KOTA : [13] SUBANG

Data Kemendagri			MFD 2021 Semester 2		
No	Kode	Nama Kecamatan	No	Kode	Nama Kecamatan
25	32.13.11	PAMANUKAN	25	3213190	PAMANUKAN
26	32.13.24	SUKASARI	26	3213191	SUKASARI
27	32.13.10	PUSAKANAGARA	27	3213200	PUSAKANAGARA
28	32.13.30	PUSAKAJAYA	28	3213201	PUSAKAJAYA
29	32.13.21	LEGONKULON	29	3213210	LEGONKULON
30	32.13.13	BLANAKAN	30	3213220	BLANAKAN

https://jabar.bps.go.id

JUMLAH DESA/KELURAHAN PER KECAMATAN

PROVINSI : [32] JAWA BARAT
KAB/KOTA : [13] SUBANG

Data Kemendagri				MFD 2021 Semester 2			
No	Kode	Nama Kecamatan	Jml Desa	No	Kode	Nama Kecamatan	Jml Desa
1	32.13.01	SAGALA-HERANG	7	1	3213010	SAGALA-HERANG	7
2	32.13.23	SERANGPAN-JANG	6	2	3213011	SERANGPAN-JANG	6
3	32.13.12	JALANCAGAK	7	3	3213020	JALANCAGAK	7
4	32.13.29	CIATER	7	4	3213021	CIATER	7
5	32.13.02	CISALAK	9	5	3213030	CISALAK	9
6	32.13.26	KASOMALANG	8	6	3213031	KASOMALANG	8
7	32.13.14	TANJUNGSIANG	10	7	3213040	TANJUNGSIANG	10
8	32.13.19	CIJAMBE	8	8	3213050	CIJAMBE	8
9	32.13.17	CIBOGO	9	9	3213060	CIBOGO	9
10	32.13.03	SUBANG	8	10	3213070	SUBANG	8
11	32.13.04	KALIJATI	10	11	3213080	KALIJATI	10
12	32.13.27	DAWUAN	10	12	3213081	DAWUAN	10
13	32.13.20	CIPEUNDEUY	7	13	3213090	CIPEUNDEUY	7
14	32.13.05	PABUARAN	8	14	3213100	PABUARAN	8
15	32.13.16	PATOKBEUSI	10	15	3213110	PATOKBEUSI	10
16	32.13.06	PURWADADI	10	16	3213120	PURWADADI	10
17	32.13.22	CIKAUM	9	17	3213130	CIKAUM	9
18	32.13.07	PAGADEN	10	18	3213140	PAGADEN	10
19	32.13.28	PAGADEN BARAT	9	19	3213141	PAGADEN BARAT	9
20	32.13.18	CIPUNAGARA	10	20	3213150	CIPUNAGARA	10
21	32.13.15	COMPRENG	8	21	3213160	COMPRENG	8
22	32.13.08	BINONG	9	22	3213170	BINONG	9
23	32.13.25	TAMBAKDAHAN	9	23	3213171	TAMBAKDAHAN	9

https://jabar.bps.go.id

JUMLAH DESA/KELURAHAN PER KECAMATAN

PROVINSI : [32] JAWA BARAT
KAB/KOTA : [13] SUBANG

Data Kemendagri				MFD 2021 Semester 2			
No	Kode	Nama Kecamatan	Jml Desa	No	Kode	Nama Kecamatan	Jml Desa
24	32.13.09	CIASEM	9	24	3213180	CIASEM	9
25	32.13.11	PAMANUKAN	8	25	3213190	PAMANUKAN	8
26	32.13.24	SUKASARI	7	26	3213191	SUKASARI	7
27	32.13.10	PUSAKANAGARA	7	27	3213200	PUSAKANAGARA	7
28	32.13.30	PUSAKAJAYA	8	28	3213201	PUSAKAJAYA	8
29	32.13.21	LEGONKULON	7	29	3213210	LEGONKULON	7
30	32.13.13	BLANAKAN	9	30	3213220	BLANAKAN	9

Catatan :
*) 1. Perkotaan
2. Perdesaan

https://jabar.bps.go.id

PROVINSI : [32] JAWA BARAT
KAB/KOTA : [13] SUBANG
KECAMATAN : [010] SAGALA HERANG

Data Kemendagri			MFD 2021 Semester 2			
No	Kode	Nama Desa	No	Kode	Nama Desa	Status*
1	32.13.01.2003	SUKAMANDI	1	3213010003	SUKAMANDI	2
2	32.13.01.2004	CICADAS	2	3213010004	CICADAS	2
3	32.13.01.2005	SAGALA-HERANG KIDUL	3	3213010005	SAGALA-HERANG	1
4	32.13.01.2006	DAYEUH KOLOT	4	3213010006	DAYEUHKOLOT	2
5	32.13.01.2009	LELES	5	3213010011	LELES	2
6	32.13.01.2011	SAGALA-HERANG KALER	6	3213010012	SAGALA-HERANG KALER	1
7	32.13.01.2010	CURUGAGUNG	7	3213010013	CURUGAGUNG	2

Catatan :
*) 1. Perkotaan
2. Perdesaan

https://jabar.bps.go.id

DAFTAR DESA/KELURAHAN

PROVINSI : [32] JAWA BARAT
KAB/KOTA : [13] SUBANG
KECAMATAN : [011] SERANGPANJANG

Data Kemendagri			MFD 2021 Semester 2			
No	Kode	Nama Desa	No	Kode	Nama Desa	Status*
1	32.13.23.2006	CIPANCAR	1	3213011001	CIPANCAR	2
2	32.13.23.2005	CIKUJANG	2	3213011002	CIKUJANG	2
3	32.13.23.2001	CIJENGKOL	3	3213011003	CIJENGKOL	2
4	32.13.23.2003	CINTAMEKAR	4	3213011004	CINTAMEKAR	2
5	32.13.23.2004	PONGGANG	5	3213011005	PONGGANG	2
6	32.13.23.2002	TALAGASARI	6	3213011006	TALAGASARI	2

Catatan :
*) 1. Perkotaan
2. Perdesaan

https://jabar.bps.go.id

PROVINSI : [32] JAWA BARAT
KAB/KOTA : [13] SUBANG
KECAMATAN : [020] JALAN CAGAK

Data Kemendagri			MFD 2021 Semester 2			
No	Kode	Nama Desa	No	Kode	Nama Desa	Status*
1	32.13.12.2007	CURUG RENDENG	1	3213020007	CURUG RENDENG	2
2	32.13.12.2012	SARIREJA	2	3213020008	SARIREJA	1
3	32.13.12.2011	KUMPAY	3	3213020013	KUMPAY	2
4	32.13.12.2008	TAMBAKAN	4	3213020014	TAMBAKAN	1
5	32.13.12.2017	JALAN CAGAK	5	3213020015	JALAN CAGAK	1
6	32.13.12.2009	BUNIHAYU	6	3213020016	BUNIHAYU	1
7	32.13.12.2014	TAMBAK MEKAR	7	3213020017	TAMBAK MEKAR	2

Catatan :
*) 1. Perkotaan
2. Perdesaan

https://jabar.bps.go.id

DAFTAR DESA/KELURAHAN

PROVINSI : [32] JAWA BARAT
KAB/KOTA : [13] SUBANG
KECAMATAN : [021] CIATER

Data Kemendagri			MFD 2021 Semester 2			
No	Kode	Nama Desa	No	Kode	Nama Desa	Status*
1	32.13.29.2002	CIATER	1	3213021001	CIATER	1
2	32.13.29.2003	NAGRAK	2	3213021002	NAGRAK	2
3	32.13.29.2004	CIBEUSI	3	3213021003	CIBEUSI	2
4	32.13.29.2005	CIBITUNG	4	3213021004	CIBITUNG	2
5	32.13.29.2007	SANCA	5	3213021005	SANCA	2
6	32.13.29.2006	PALASARI	6	3213021006	PALASARI	1
7	32.13.29.2001	CISAAT	7	3213021007	CISAAT	2

Catatan :
*) 1. Perkotaan
2. Perdesaan

https://jabar.bps.go.id

PROVINSI : [32] JAWA BARAT
KAB/KOTA : [13] SUBANG
KECAMATAN : [030] CISALAK

Data Kemendagri			MFD 2021 Semester 2			
No	Kode	Nama Desa	No	Kode	Nama Desa	Status*
1	32.13.02.2001	CUPUNAGARA	1	3213010001	CUPUNAGARA	2
2	32.13.02.2002	CIMANGGU	2	3213010002	CIMANGGU	2
3	32.13.02.2003	GARDU SAYANG	3	3213010003	GARDU SAYANG	1
4	32.13.02.2004	MAYANG	4	3213010004	MAYANG	2
5	32.13.02.2005	SUKAKERTI	5	3213010005	SUKAKERTI	2
6	32.13.02.2007	DARMAGA	6	3213010008	DARMAGA	1
7	32.13.02.2008	CISALAK	7	3213010009	CISALAK	1
8	32.13.02.2011	CIGADOG	8	3213010010	CIGADOG	1
9	32.13.02.2014	PAKUHAJI	9	3213010011	PAKUHAJI	2

Catatan :
*) 1. Perkotaan
2. Perdesaan

https://jabar.bps.go.id

DAFTAR DESA/KELURAHAN

PROVINSI : [32] JAWA BARAT
KAB/KOTA : [13] SUBANG
KECAMATAN : [031] KASOMALANG

Data Kemendagri			MFD 2021 Semester 2			
No	Kode	Nama Desa	No	Kode	Nama Desa	Status*
1	32.13.26.2002	PASANGGRA-HAN	1	3213031001	PASANGGRA-HAN	2
2	32.13.26.2001	SINDANGSARI	2	3213031002	SINDANGSARI	1
3	32.13.26.2003	BOJONGLOA	3	3213031003	BOJONGLOA	2
4	32.13.26.2005	TENJOLAYA	4	3213031004	TENJOLAYA	2
5	32.13.26.2004	SUKAMELANG	5	3213031005	SUKAMELANG	2
6	32.13.26.2006	KASOMALANG WETAN	6	3213031006	KASOMALANG WETAN	1
7	32.13.26.2007	KASOMALANG KULON	7	3213031007	KASOMALANG KULON	1
8	32.13.26.2008	CIMANGLID	8	3213031008	CIMANGLID	2

Catatan :
*) 1. Perkotaan
2. Perdesaan

https://jabar.bps.go.id

PROVINSI : [32] JAWA BARAT
KAB/KOTA : [13] SUBANG
KECAMATAN : [040] TANJUNGSIANG

Data Kemendagri			MFD 2021 Semester 2			
No	Kode	Nama Desa	No	Kode	Nama Desa	Status*
1	32.13.14.2001	BUNIARA	1	3213040001	BUNIARA	2
2	32.13.14.2002	TANJUNG-SIANG	2	3213040002	TANJUNG-SIANG	1
3	32.13.14.2009	CIKAWUNG	3	3213040003	CIKAWUNG	2
4	32.13.14.2003	CIMEUHMAL	4	3213040004	CIMEUHMAL	2
5	32.13.14.2004	SIRAP	5	3213040005	SIRAP	2
6	32.13.14.2005	KAWUNGLU-WUK	6	3213040006	KAWUNGLU-WUK	2
7	32.13.14.2006	CIBULUH	7	3213040008	CIBULUH	2
8	32.13.14.2007	SINDANGLAYA	8	3213040009	SINDANGLAYA	2
9	32.13.14.2008	RANCAMANG-GUNG	9	3213040010	RANCAMANG-GUNG	2
10	32.13.14.2010	GANDASOLI	10	3213040011	GANDASOLI	2

Catatan :
*) 1. Perkotaan
2. Perdesaan

https://jabar.bps.go.id

DAFTAR DESA/KELURAHAN

PROVINSI : [32] JAWA BARAT
KAB/KOTA : [13] SUBANG
KECAMATAN : [050] CIJAMBE

Data Kemendagri			MFD 2021 Semester 2			
No	Kode	Nama DESA	No	Kode	Nama Desa	Status*
1	32.13.19.2001	GUNUNGTUA	1	3213050001	GUNUNG TUA	2
2	32.13.19.2002	CIJAMBE	2	3213050002	CIJAMBE	2
3	32.13.19.2003	CIRANGKONG	3	3213050003	CIRANGKONG	2
4	32.13.19.2004	CIMENTENG	4	3213050004	CIMENTENG	2
5	32.13.19.2007	CIKADU	5	3213050005	CIKADU	2
6	32.13.19.2008	SUKAHURIP	6	3213050006	SUKAHURIP	2
7	32.13.19.2005	BANTARSARI	7	3213050007	BANTARSARI	2
8	32.13.19.2006	TANNJUNG WANGI	8	3213050008	TANJUNG WANGI	2

Catatan :
*) 1. Perkotaan
2. Perdesaan

https://jabar.bps.go.id

PROVINSI : [32] JAWA BARAT
KAB/KOTA : [13] SUBANG
KECAMATAN : [060] CIBOGO

Data Kemendagri			MFD 2021 Semester 2			
No	Kode	Nama Desa	No	Kode	Nama Desa	Status*
1	32.13.17.2005	SADAWARNA	1	3213060002	SADAWARNA	2
2	32.13.17.2001	SUMURBA-RANG	2	3213060003	SUMURBA-RANG	2
3	32.13.17.2004	PADAASIH	3	3213060004	PADAASIH	2
4	32.13.17.2002	CIBOGO	4	3213060005	CIBOGO	1
5	32.13.17.2003	CINANGSI	5	3213060006	CINANGSI	1
6	32.13.17.2006	MAJASARI	6	3213060007	MAJASARI	2
7	32.13.17.2009	CIBALANDONG JAYA	7	3213060008	CIBALAND-ONGJAYA	2
8	32.13.17.2008	BELENDUNG	8	3213060009	BELENDUNG	2
9	32.13.17.2007	CISAGA	9	3213060010	CISAGA	2

https://jabar.bps.go.id

Catatan :
*) 1. Perkotaan
2. Perdesaan

DAFTAR DESA/KELURAHAN

PROVINSI : [32] JAWA BARAT
KAB/KOTA : [13] SUBANG
KECAMATAN : [070] SUBANG

Data Kemendagri			MFD 2021 Semester 2			
No	Kode	Nama Desa	No	Kode	Nama Desa	Status*
1	32.13.03.1001	PARUNG	1	3213070001	PARUNG	2
2	32.13.03.1003	PASIRKAREUM-BI	2	3213070002	PASIRKAREUM-BI	1
3	32.13.03.1005	SOKLAT	3	3213070003	SOKLAT	1
4	32.13.03.1004	KARANG ANYAR	4	3213070004	KARANG ANYAR	1
5	32.13.03.1002	CIGADUNG	5	3213070005	CIGADUNG	1
6	32.13.03.1007	DANGDEUR	6	3213070006	DANGDEUR	1
7	32.13.03.1006	SUKAMELANG	7	3213070007	SUKAMELANG	1
8	32.13.03.1008	WANAREJA	8	3213070008	WANAREJA	2

Catatan :
*) 1. Perkotaan
2. Perdesaan

https://jabar.bps.go.id

PROVINSI : [32] JAWA BARAT
KAB/KOTA : [13] SUBANG
KECAMATAN : [080] KALIJATI

Data Kemendagri			MFD 2021 Semester 2			
No	Kode	Nama Desa	No	Kode	Nama Desa	Status*
1	32.13.04.2012	TANGGULUN TIMUR	1	3213080004	TANGGULUN TIMUR	2
2	32.13.04.2013	TANGGULUN BARAT	2	3213080005	TANGGULUN BARAT	1
3	32.13.04.2006	MARENG-MANG	3	3213080006	MARENG-MANG	2
4	32.13.04.2011	KALIJATI BARAT	4	3213080007	KALIJATI BARAT	1
5	32.13.04.2007	KALIJATI TIMUR	5	3213080008	KALIJATI TIMUR	1
6	32.13.04.2008	KALIANGSANA	6	3213080016	KALIANGSANA	2
7	32.13.04.2020	BANGGALA MULYA	7	3213080017	BANGGALA MULYA	2
8	32.13.04.2019	JALUPANG	8	3213080018	JALUPANG	2
9	32.13.04.2017	CIRACAS	9	3213080019	CIRACAS	2
10	32.13.04.2018	CIRULUK	10	3213080020	CIRULUK	2

Catatan :
*) 1. Perkotaan
2. Perdesaan

https://jabar.bps.go.id

DAFTAR DESA/KELURAHAN

PROVINSI : [32] JAWA BARAT
KAB/KOTA : [13] SUBANG
KECAMATAN : [081] DAWUAN

Data Kemendagri			MFD 2021 Semester 2			
No	**Kode**	**Nama Desa**	**No**	**Kode**	**Nama Desa**	**Status***
1	32.13.27.2010	JAMBELAER	1	3213081001	JAMBELAER	2
2	32.13.27.2008	MARGASARI	2	3213081002	MARGASARI	2
3	32.13.27.2007	CISAMPIH	3	3213081003	CISAMPIH	2
4	32.13.27.2004	SITUSARI	4	3213081004	SITUSARI	2
5	32.13.27.2003	SUKASARI	5	3213081005	SUKASARI	1
6	32.13.27.2002	RAWALELE	6	3213081006	RAWALELE	1
7	32.13.27.2006	DAWUAN KIDUL	7	3213081007	DAWUAN KIDUL	2
8	32.13.27.2005	DAWUAN KALER	8	3213081008	DAWUAN KALER	2
9	32.13.27.2001	MANYETI	9	3213081009	MANYETI	2
10	32.13.27.2009	BATUSARI	10	3213081010	BATUSARI	2

Catatan :
*) 1. Perkotaan
2. Perdesaan

https://jabar.bps.go.id

PROVINSI : [32] JAWA BARAT
KAB/KOTA : [13] SUBANG
KECAMATAN : [090] CIPEUNDEUY

Data Kemendagri			MFD 2021 Semester 2			
No	Kode	Nama Desa	No	Kode	Nama Desa	Status*
1	32.13.20.2002	CIMAYASARI	1	3213090003	CIMAYASARI	2
2	32.13.20.2003	LENGKONG	2	3213090004	LENGKONG	2
3	32.13.20.2004	CIPEUNDEUY	3	3213090005	CIPEUNDEUY	1
4	32.13.20.2005	WANTILAN	4	3213090006	WANTILAN	2
5	32.13.20.2007	SAWANGAN	5	3213090007	SAWANGAN	2
6	32.13.20.2001	KARYAMUKTI	6	3213090008	KARANGMUKTI	2
7	32.13.20.2006	KOSAR	7	3213090009	KOSAR	2

Catatan :
*) 1. Perkotaan
2. Perdesaan

https://jabar.bps.go.id

DAFTAR DESA/KELURAHAN

PROVINSI : [32] JAWA BARAT
KAB/KOTA : [13] SUBANG
KECAMATAN : [100] PABUARAN

Data Kemendagri			MFD 2021 Semester 2			
No	Kode	Nama Desa	No	Kode	Nama Desa	Status*
1	32.13.05.2001	CIHAMBULU	1	3213100002	CIHAMBULU	2
2	32.13.05.2002	SILUMAN	2	3213100003	SILUMAN	2
3	32.13.05.2004	PABUARAN	3	3213100004	PABUARAN	1
4	32.13.05.2006	SALAMJAYA	4	3213100005	SALAMJAYA	2
5	32.13.05.2007	KADAWUNG	5	3213100006	KADAWUNG	2
6	32.13.05.2003	PRINGKASAP	6	3213100007	PRINGKASAP	2
7	32.13.05.2005	KARANGHE-GAR	7	3213100008	KARANGHE-GAR	2
8	32.13.05.2008	BALEBAN DUNG JAYA	8	3213100011	BALEBAN DUNG JAYA	2

Catatan :
*) 1. Perkotaan
2. Perdesaan

https://jabar.bps.go.id

PROVINSI : [32] JAWA BARAT
KAB/KOTA : [13] SUBANG
KECAMATAN : [110] PATOKBEUSI

Data Kemendagri			MFD 2021 Semester 2			
No	Kode	Nama Desa	No	Kode	Nama Desa	Status*
1	32.13.16.2008	TANJUNGRASA KIDUL	1	3213110001	TANJUNGRASA KIDUL	2
2	32.13.16.2002	TANJUNGRASA	2	3213110002	TANJUNGRASA	2
3	32.13.16.2004	JATIRAGAS HILIR	3	3213110003	JATIRAGAS HILIR	2
4	32.13.16.2005	TAMBAKJATI	4	3213110004	TAMBAKJATI	2
5	32.13.16.2003	CIBERES	5	3213110005	CIBERES	2
6	32.13.16.2007	GEMPOLSARI	6	3213110006	GEMPOLSARI	2
7	32.13.16.2010	RANCAMULYA	7	3213110007	RANCAMULYA	2
8	32.13.16.2006	RANCAJAYA	8	3213110008	RANCAJAYA	2
9	32.13.16.2001	RANCABANGO	9	3213110009	RANCABANGO	2
10	32.13.16.2009	RANCAASIH	10	3213110010	RANCAASIH	2

https://jabar.bps.go.id

Catatan :
*) 1. Perkotaan
2. Perdesaan

DAFTAR DESA/KELURAHAN

PROVINSI : [32] JAWA BARAT
KAB/KOTA : [13] SUBANG
KECAMATAN : [120] PURWADADI

Data Kemendagri			MFD 2021 Semester 2			
No	Kode	Nama Desa	No	Kode	Nama Desa	Status*
1	32.13.06.2006	KORANJI	1	3213120001	KORANJI	2
2	32.13.06.2005	BELENDUNG	2	3213120002	BELENDUNG	2
3	32.13.06.2001	WANAKERTA	3	3213120003	WANAKERTA	2
4	32.13.06.2002	PAGON	4	3213120004	PAGON	2
5	32.13.06.2003	PARAPATAN	5	3213120005	PARAPATAN	2
6	32.13.06.2004	PURWADADI	6	3213120006	PURWADADI	1
7	32.13.06.2009	PURWADADI BARAT	7	3213120007	PURWADADI BARAT	1
8	32.13.06.2008	PASIRBUNGUR	8	3213120008	PASIRBUNGUR	1
9	32.13.06.2010	RANCAMAHI	9	3213120009	RANCAMAHI	2
10	32.13.06.2007	PANYINGKIRAN	10	3213120010	PANYINGKIRAN	2

https://jabar.bps.go.id

Catatan :
*) 1. Perkotaan
2. Perdesaan

PROVINSI : [32] JAWA BARAT
KAB/KOTA : [13] SUBANG
KECAMATAN : [130] CIKAUM

Data Kemendagri			MFD 2021 Semester 2			
No	Kode	Nama Desa	No	Kode	Nama Desa	Status*
1	32.13.22.2001	KAWUNG ANTEN	1	3213130001	KAWUNG ANTEN	2
2	32.13.22.2002	SINDANGSARI	2	3213130002	SINDANGSARI	2
3	32.13.22.2004	CIKAUM TIMUR	3	3213130003	CIKAUM TIMUR	2
4	32.13.22.2003	CIKAUM BARAT	4	3213130004	CIKAUM BARAT	2
5	32.13.22.2009	PASIR MUN-CANG	5	3213130005	PASIR MUN-CANG	2
6	32.13.22.2008	GANDASARI	6	3213130006	GANDASARI	2
7	32.13.22.2006	MEKARSARI	7	3213130007	MEKARSARI	2
8	32.13.22.2005	TANJUNGSARI BARAT	8	3213130008	TANJUNGSARI BARAT	2
9	32.13.22.2007	TANJUNGSARI-TIMUR	9	3213130010	TANJUNGSARI-TIMUR	2

https://jabar.bps.go.id

Catatan :
*) 1. Perkotaan
2. Perdesaan

DAFTAR DESA/KELURAHAN

PROVINSI : [32] JAWA BARAT
KAB/KOTA : [13] SUBANG
KECAMATAN : [140] PAGADEN

Data Kemendagri			MFD 2021 Semester 2			
No	Kode	Nama Desa	No	Kode	Nama Desa	Status*
1	32.13.07.2004	GUNUNGSEM-BUNG	1	3213140004	GUNUNGSEM-BUNG	2
2	32.13.07.2005	GEMBOR	2	3213140005	GEMBOR	2
3	32.13.07.2015	GUNUNGSARI	3	3213140006	GUNUNGSARI	2
4	32.13.07.2012	SUKAMULYA	4	3213140007	SUKAMULYA	1
5	32.13.07.2014	SUMBERSARI	5	3213140013	SUMBERSARI	2
6	32.13.07.2010	GEMBARSARI	6	3213140014	GEMBARSARI	2
7	32.13.07.2013	NEGLASARI	7	3213140015	NEGLASARI	2
8	32.13.07.2011	PAGADEN	8	3213140016	PAGADEN	1
9	32.13.07.2006	KAMARUNG	9	3213140017	KAMARUNG	1
10	32.13.07.2019	JABONG	10	3213140018	JABONG	1

Catatan :
*) 1. Perkotaan
2. Perdesaan

https://jabar.bps.go.id

PROVINSI : [32] JAWA BARAT
KAB/KOTA : [13] SUBANG
KECAMATAN : [141] PAGADEN BARAT

Data Kemendagri			MFD 2021 Semester 2			
No	Kode	Nama Desa	No	Kode	Nama Desa	Status*
1	32.13.28.2007	BALIMBING	1	321341001	BALINGBING	2
2	32.13.28.2009	CIDADAP	2	321341002	CIDADAP	2
3	32.13.28.2008	CIDAHU	3	321341003	CIDAHU	2
4	32.13.28.2005	PANGSOR	4	321341004	PANGSOR	2
5	32.13.28.2003	MUNJUL	5	321341005	MUNJUL	2
6	32.13.28.2004	MARGAHAYU	6	321341006	MARGAHAYU	2
7	32.13.28.2002	BENDUNGAN	7	321341007	BENDUNGAN	2
8	32.13.28.2001	MEKARWANGI	8	321341008	MEKARWANGI	2
9	32.13.28.2006	SUMURGIN-TUNG	9	321341009	SUMURGIN-TUNG	2

Catatan :
*) 1. Perkotaan
2. Perdesaan

https://jabar.bps.go.id

DAFTAR DESA/KELURAHAN

PROVINSI : [32] JAWA BARAT
KAB/KOTA : [13] SUBANG
KECAMATAN : [150] CIPUNAGARA

Data Kemendagri			MFD 2021 Semester 2			
No	Kode	Nama Desa	No	Kode	Nama Desa	Status*
1	32.13.18.2001	WANASARI	1	3213150001	WANASARI	2
2	32.13.18.2002	SIDAMULYA	2	3213150002	SIDAMULYA	2
3	32.13.18.2007	SIDAJAYA	3	3213150003	SIDAJAYA	2
4	32.13.18.2003	TANJUNG	4	3213150004	TANJUNG	2
5	32.13.18.2006	PARIGI MULYA	5	3213150005	PARIGI MULYA	2
6	32.13.18.2010	MANYINGSAL	6	3213150006	MANYINGSAL	2
7	32.13.18.2008	PADAMULYA	7	3213150007	PADAMULYA	2
8	32.13.18.2004	JATI	8	3213150008	JATI	2
9	32.13.18.2009	KOSAMBI	9	3213150009	KOSAMBI	2
10	32.13.18.2005	SIMPAR	10	3213150010	SIMPAR	2

https://jabar.bps.go.id

Catatan :
*) 1. Perkotaan
2. Perdesaan

PROVINSI : [32] JAWA BARAT
KAB/KOTA : [13] SUBANG
KECAMATAN : [160] COMPRENG

Data Kemendagri			MFD 2021 Semester 2			
No	Kode	Nama Desa	No	Kode	Nama Desa	Status*
1	32.13.15.2008	SUKADANA	1	3213160001	SUKADANA	2
2	32.13.15.2002	SUKATANI	2	3213160002	SUKATANI	2
3	32.13.15.2007	KIARASARI	3	3213160003	KIARASARI	1
4	32.13.15.2003	JATIREJA	4	3213160004	JATIREJA	2
5	32.13.15.2006	MEKARJAYA	5	3213160005	MEKARJAYA	2
6	32.13.15.2005	KALENSARI	6	3213160006	KALENSARI	2
7	32.13.15.2004	COMPRENG	7	3213160007	COMPRENG	1
8	32.13.15.2001	JATIMULYA	8	3213160008	JATIMULYA	2

Catatan :
*) 1. Perkotaan
2. Perdesaan

https://jabar.bps.go.id

DAFTAR DESA/KELURAHAN

PROVINSI : [32] JAWA BARAT
KAB/KOTA : [13] SUBANG
KECAMATAN : [170] BINONG

Data Kemendagri			MFD 2021 Semester 2			
No	Kode	Nama Desa	No	Kode	Nama Desa	Status*
1	32.13.08.2018	NANGGERANG	1	3213170001	NANGERANG	2
2	32.13.08.2001	CICADAS	2	3213170002	CICADAS	2
3	32.13.08.2002	KIHIYANG	3	3213170003	KIHIYANG	2
4	32.13.08.2014	KARANGSARI	4	3213170004	KARANGSARI	2
5	32.13.08.2010	CITRAJAYA	5	3213170005	CITRAJAYA	2
6	32.13.08.2003	BINONG	6	3213170006	BINONG	1
7	32.13.08.2004	KEDIRI	7	3213170007	KEDIRI	2
8	32.13.08.2011	MULYASARI	8	3213170008	MULYASARI	2
9	32.13.08.2016	KARANG WANGI	9	3213170018	KARANG WANGI	2

Catatan :
*) 1. Perkotaan
2. Perdesaan

https://jabar.bps.go.id

PROVINSI : [32] JAWA BARAT
KAB/KOTA : [13] SUBANG
KECAMATAN : [171] TAMBAK DAHAN

Data Kemendagri			MFD 2021 Semester 2			
No	Kode	Nama Desa	No	Kode	Nama Desa	Status*
1	32.13.25.2001	TANJUNGRASA	1	3213171001	TANJUNGRASA	2
2	32.13.25.2002	WANAJAYA	2	3213171002	WANAJAYA	2
3	32.13.25.2003	GARDUMUKTI	3	3213171003	GARDUMUKTI	2
4	32.13.25.2004	MARIUK	4	3213171004	MARIUK	2
5	32.13.25.2005	KERTAJAYA	5	3213171005	KERTAJAYA	2
6	32.13.25.2006	TAMBAKDA-HAN	6	3213171006	TAMBAKDA-HAN	2
7	32.13.25.2008	BOJONG KEDING	7	3213171007	BOJONG KEDING	2
8	32.13.25.2009	BOJONEGARA	8	3213171008	BOJONEGARA	2
9	32.13.25.2007	RANCAUDIK	9	3213171009	RANCAUDIK	2

Catatan :
*) 1. Perkotaan
2. Perdesaan

https://jabar.bps.go.id

DAFTAR DESA/KELURAHAN

PROVINSI : [32] JAWA BARAT
KAB/KOTA : [13] SUBANG
KECAMATAN : [180] CIASEM

Data Kemendagri			MFD 2021 Semester 2			
No	Kode	Nama Desa	No	Kode	Nama Desa	Status*
1	32.13.09.2006	SUKAMANDI JAYA	1	3213180001	SUKAMANDI JAYA	1
2	32.13.09.2002	CIASEM TEN-GAH	2	3213180002	CIASEM TEN-GAH	2
3	32.13.09.2003	DUKUH	3	3213180003	DUKUH	2
4	32.13.09.2009	JATIBARU	4	3213180004	JATIBARU	2
5	32.13.09.2004	CIASEM HILIR	5	3213180006	CIASEM HILIR	2
6	32.13.09.2007	CIASEM BARU	6	3213180007	CIASEM BARU	1
7	32.13.09.2001	CIASEM GI-RANG	7	3213180008	CIASEM GI-RANG	1
8	32.13.09.2005	SUKAHAJI	8	3213180009	SUKAHAJI	2
9	32.13.09.2008	PINANGSARI	9	3213180010	PINANGSARI	2

https://jabar.bps.go.id

Catatan :
*) 1. Perkotaan
2. Perdesaan

PROVINSI : [32] JAWA BARAT
KAB/KOTA : [13] SUBANG
KECAMATAN : [190] PAMANUKAN

Data Kemendagri			MFD 2021 Semester 2			
No	Kode	Nama Desa	No	Kode	Nama Desa	Status*
1	32.13.11.2002	RANCASARI	1	3213190006	RANCASARI	1
2	32.13.11.2004	PAMANUKAN	2	3213190007	PAMANUKAN	1
3	32.13.11.2006	PAMANUKAN HILIR	3	3213190008	PAMANUKAN HILIR	1
4	32.13.11.2010	LENGKONG-JAYA	4	3213190009	LENGKONG-JAYA	1
5	32.13.11.2007	PAMANUKAN SEBRANG	5	3213190010	PAMANUKAN SEBRANG	2
6	32.13.11.2009	MULYASARI	6	3213190012	MULYASARI	1
7	32.13.11.2003	RANCAHILIR	7	3213190013	RANCAHILIR	2
8	32.13.11.2011	BONGAS		3213190014	BONGAS	2

Catatan :
*) 1. Perkotaan
2. Perdesaan

https://jabar.bps.go.id

DAFTAR DESA/KELURAHAN

PROVINSI : [32] JAWA BARAT
KAB/KOTA : [13] SUBANG
KECAMATAN : [191] SUKASARI

Data Kemendagri			MFD 2021 Semester 2			
No	Kode	Nama Desa	No	Kode	Nama Desa	Status*
1	32.13.24.2004	MANDALA-WANGI	1	3213191001	MANDALA-WANGI	2
2	32.13.24.2005	CURUGREJA	2	3213191002	CURUGREJA	2
3	32.13.24.2002	BATANGSARI	3	3213191003	BATANGSARI	2
4	32.13.24.2007	SUKASARI	4	3213191004	SUKASARI	2
5	32.13.24.2006	SUKAREJA	5	3213191005	SUKAREJA	2
6	32.13.24.2001	ANGGASARI	6	3213191006	ANGGASARI	2
7	32.13.24.2003	SUKAMAJU	7	3213191007	SUKAMAJU	2

Catatan :
*) 1. Perkotaan
2. Perdesaan

https://jabar.bps.go.id

PROVINSI : [32] JAWA BARAT
KAB/KOTA : [13] SUBANG
KECAMATAN : [200] PUSAKANAGARA

Data Kemendagri			MFD 2021 Semester 2			
No	Kode	Nama Desa	No	Kode	Nama Desa	Status*
1	32.13.10.2005	PUSAKARATU	1	3213200009	PUSAKARATU	1
2	32.13.10.2006	GEMPOL	2	3213200010	GEMPOL	2
3	32.13.10.2007	KALENTAMBO	3	3213200011	KALENTAMBO	2
4	32.13.10.2008	KOTASARI	4	3213200012	KOTASARI	1
5	32.13.10.2014	RANCADAKA	5	3213200013	RANCADAKA	2
6	32.13.10.2012	PATIMBAN	6	3213200014	PATIMBAN	2
7	32.13.10.2008	MUNDUSARI	7	3213200015	MUNDUSARI	2

Catatan :
*) 1. Perkotaan
2. Perdesaan

https://jabar.bps.go.id

DAFTAR DESA/KELURAHAN

PROVINSI : [32] JAWA BARAT
KAB/KOTA : [13] SUBANG
KECAMATAN : [201] PUSAKAJAYA

Data Kemendagri			MFD 2021 Semester 2			
No	Kode	Nama Desa	No	Kode	Nama Desa	Status*
1	32.13.30.2004	BOJONG TENGAH	1	3213201001	BOJONG TENGAH	2
2	32.13.30.2005	BOJONGJAYA	2	3213201002	BOJONGJAYA	2
3	32.13.30.2006	CIGUGUR	3	3213201003	CIGUGUR	2
4	32.13.30.2007	CIGUGUR KALER	4	3213201004	CIGUGUR KALER	2
5	32.13.30.2008	RANGDU	5	3213201005	RANGDU	2
6	32.13.30.2003	KARANGANYAR	6	3213201006	KARANGANYAR	2
7	32.13.30.2001	KEBONDANAS	7	3213201007	KEBONDANAS	2
8	32.13.30.2002	PUSAKAJAYA	8	3213201008	PUSAKAJAYA	1

Catatan :
*) 1. Perkotaan
2. Perdesaan

https://jabar.bps.go.id

PROVINSI : [32] JAWA BARAT
KAB/KOTA : [13] SUBANG
KECAMATAN : [210] LEGON KULON

Data Kemendagri			MFD 2021 Semester 2			
No	Kode	Nama Desa	No	Kode	Nama Desa	Status*
1	32.13.21.2001	TEGALURUNG	1	3213210002	TEGALURUNG	2
2	32.13.21.2004	MAYANGAN	2	3213210003	MAYANGAN	2
3	32.13.21.2005	LEGONWETAN	3	3213210004	LEGONWETAN	2
4	32.13.21.2003	LEGONKULON	4	3213210005	LEGONKULON	2
5	32.13.21.2006	PANGARENG AN	5	3213210006	PANGARENG AN	2
6	32.13.21.2002	BOBOS	6	3213210007	BOBOS	2
7	32.13.21.2007	KARANGMULYA	7	3213210008	KARANGMULYA	1

Catatan :
*) 1. Perkotaan
2. Perdesaan

https://jabar.bps.go.id

DAFTAR DESA/KELURAHAN

PROVINSI : [32] JAWA BARAT
KAB/KOTA : [13] SUBANG
KECAMATAN : [220] BLANAKAN

Data Kemendagri			MFD 2021 Semester 2			
No	Kode	Nama Desa	No	Kode	Nama Desa	Status*
1	32.13.13.2007	CILAMAYA-HILIR	1	3213220001	CILAMAYA HILIR	2
2	32.13.13.2005	CILAMAYA GIRANG	2	3213220002	CILAMAYA GIRANG	2
3	32.13.13.2008	RAWAMEKAR	3	3213220003	RAWAMEKAR	2
4	32.13.13.2004	RAWAMENENG	4	3213220004	RAWAMENENG	2
5	32.13.13.2006	JAYAMUKTI	5	3213220005	JAYAMUKTI	2
6	32.13.13.2003	BLANAKAN	6	3213220006	BLANAKAN	2
7	32.13.13.2009	LANGENSARI	7	3213220007	LANGENSARI	2
8	32.13.13.2002	MUARA	8	3213220008	MUARA	2
9	32.13.13.2001	TANJUNGTIGA	9	3213220009	TANJUNGTIGA	2

Catatan :
*) 1. Perkotaan
2. Perdesaan

https://jabar.bps.go.id

KABUPATEN PURWAKARTA

https://jabar.bps.go.id

https://jabar.bps.go.id

PROVINSI : [32] JAWA BARAT
KABUPATEN : [14] PURWAKARTA

Data Kemendagri			MFD 2021 Semester 2		
No	Kode	Nama Kecamatan	No	Kode	Nama Kecamatan
1	32.14.03	JATILUHUR	1	3214010	JATILUHUR
2	32.14.15	SUKASARI	2	3214011	SUKASARI
3	32.14.07	MANIIS	3	3214020	MANIIS
4	32.14.08	TEGALWARU	4	3214030	TEGAL WARU
5	32.14.04	PLERED	5	3214040	PLERED
6	32.14.05	SUKATANI	6	3214050	SUKATANI
7	32.14.06	DARANGDAN	7	3214060	DARANGDAN
8	32.14.11	BOJONG	8	3214070	BOJONG
9	32.14.09	WANAYASA	9	3214080	WANAYASA
10	32.14.17	KIARAPEDES	10	3214081	KIARAPEDES
11	32.14.10	PASAWAHAN	11	3214090	PASAWAHAN
12	32.14.16	PONDOKSALAM	12	3214091	PONDOK SALAM
13	32.14.01	PURWAKARTA	13	3214100	PURWAKARTA
14	32.14.12	BABAKANCIKAO	14	3214101	BABAKANCIKAO
15	32.14.02	CAMPAKA	15	3214110	CAMPAKA
16	32.14.14	CIBATU	16	3214111	CIBATU
17	32.14.13	BUNGURSARI	17	3214112	BUNGURSARI

https://jabar.bps.go.id

JUMLAH DESA/KELURAHAN PER KECAMATAN

PROVINSI : [32] JAWA BARAT
KABUPATEN : [14] PURWAKARTA

Data Kemendagri				MFD 2021 Semester 2			
No	Kode	Nama Kecamatan	Jml Desa	No	Kode	Nama Kecamatan	Jml Desa
1	32.14.03	JATILUHUR	10	1	3214010	JATILUHUR	10
2	32.14.15	SUKASARI	5	2	3214011	SUKASARI	5
3	32.14.07	MANIIS	8	3	3214020	MANIIS	8
4	32.14.08	TEGALWARU	13	4	3214030	TEGAL WARU	13
5	32.14.04	PLERED	16	5	3214040	PLERED	16
6	32.14.05	SUKATANI	14	6	3214050	SUKATANI	14
7	32.14.06	DARANGDAN	15	7	3214060	DARANGDAN	15
8	32.14.11	BOJONG	14	8	3214070	BOJONG	14
9	32.14.09	WANAYASA	15	9	3214080	WANAYASA	15
10	32.14.17	KIARAPEDES	10	10	3214081	KIARAPEDES	10
11	32.14.10	PASAWAHAN	12	11	3214090	PASAWAHAN	12
12	32.14.16	PONDOKSALAM	11	12	3214091	PONDOK SALAM	11
13	32.14.01	PURWAKARTA	10	13	3214100	PURWAKARTA	10
14	32.14.12	BABAKANCIKAO	9	14	3214101	BABAKANCIKAO	9
15	32.14.02	CAMPAKA	10	15	3214110	CAMPAKA	10
16	32.14.14	CIBATU	10	16	3214111	CIBATU	10
17	32.14.13	BUNGURSARI	10	17	3214112	BUNGURSARI	10

https://jabar.bps.go.id

PROVINSI : [32] JAWA BARAT
KABUPATEN : [14] PURWAKARTA
KECAMATAN : [010] JATILUHUR

Data Kemendagri			MFD 2021 Semester 2			
No	Kode	Nama Desa	No	Kode	Nama Desa	Status*
1	32.14.03.2002	JATIMEKAR	1	3214010006	JATIMEKAR	1
2	32.14.03.2001	CIKAOBAN DUNG	2	3214010007	CIKAOBAN DUNG	1
3	32.14.03.2003	JATILUHUR	3	3214010008	JATILUHUR	1
4	32.14.03.2004	CILEGONG	4	3214010009	CILEGONG	1
5	32.14.03.2005	KEMBANG KUNING	5	3214010010	KEMBANG KUNING	1
6	32.14.03.2006	CIBINONG	6	3214010011	CIBINONG	1
7	32.14.03.2010	PARAKANLIMA	7	3214010015	PARAKANLIMA	2
8	32.14.03.2009	CISALADA	8	3214010016	CISALADA	2
9	32.14.03.2008	MEKARGALIH	9	3214010017	MEKARGALIH	1
10	32.14.03.2007	BUNDER	10	3214010018	BUNDER	1

Catatan :
*) 1. Perkotaan
2. Perdesaan

https://jabar.bps.go.id

DAFTAR DESA/KELURAHAN

PROVINSI : [32] JAWA BARAT
KABUPATEN : [14] PURWAKARTA
KECAMATAN : [011] SUKASARI

Data Kemendagri			MFD 2021 Semester 2			
No	Kode	Nama Desa	No	Kode	Nama Desa	Status*
1	32.14.15.2001	PARUNGBAN-TENG	1	3214011001	PARUNGBAN-TENG	2
2	32.14.15.2002	SUKASARI	2	3214011002	SUKASARI	2
3	32.14.15.2003	CIRIRIP	3	3214011003	CIRIRIP	2
4	32.14.15.2004	KERTAMANAH	4	3214011004	KERTAMANAH	2
5	32.14.15.2005	KUTAMANAH	5	3214011005	KUTAMANAH	2

Catatan :
*) 1. Perkotaan
2. Perdesaan

https://jabar.bps.go.id

PROVINSI : [32] JAWA BARAT
KABUPATEN : [14] PURWAKARTA
KECAMATAN : [020] MANIIS

Data Kemendagri			MFD 2021 Semester 2			
No	Kode	Nama Desa	No	Kode	Nama Desa	Status*
1	32.14.07.2004	TEGALDATAR	1	3214020001	TEGALDATAR	2
2	32.14.07.2003	SINARGALIH	2	3214020002	SINARGALIH	2
3	32.14.07.2002	CITAMIANG	3	3214020003	CITAMIANG	2
4	32.14.07.2005	CIJATI	4	3214020004	CIJATI	2
5	32.14.07.2001	GUNUNG-KARUNG	5	3214020005	GUNUNG-KARUNG	2
6	32.14.07.2008	PASIRJAMBU	6	3214020006	PASIRJAMBU	2
7	32.14.07.2006	CIRAMAHILIR	7	3214020007	CIRAMAHILIR	2
8	32.14.07.2007	SUKAMUKTI	8	3214020008	SUKAMUKTI	2

Catatan :
*) 1. Perkotaan
2. Perdesaan

https://jabar.bps.go.id

DAFTAR DESA/KELURAHAN

PROVINSI : [32] JAWA BARAT
KABUPATEN : [14] PURWAKARTA
KECAMATAN : [030] TEGALWARU

Data Kemendagri			MFD 2021 Semester 2			
No	Kode	Nama Desa	No	Kode	Nama Desa	Status*
1	32.14.08.2007	SUKAHAJI	1	3214030001	SUKAHAJI	2
2	32.14.08.2008	KAROYA	2	3214030002	KAROYA	2
3	32.14.08.2009	CADASSARI	3	3214030003	CADASSARI	2
4	32.14.08.2010	CADASMEKAR	4	3214030004	CADASMEKAR	2
5	32.14.08.2002	CITALANG	5	3214030005	CITALANG	2
6	32.14.08.2001	BATUTUM PANG	6	3214030006	BATUTUM PANG	2
7	32.14.08.2003	TEGALWARU	7	3214030007	TEGALWARU	2
8	32.14.08.2004	TEGALSARI	8	3214030008	TEGALSARI	2
9	32.14.08.2005	WARUNGJE-RUK	9	3214030009	WARUNGJE-RUK	2
10	32.14.08.2006	GALUMPIT	10	3214030010	GALUMPIT	2
11	32.14.08.2011	CISARUA	11	3214030011	CISARUA	2
12	32.14.08.2012	SUKAMULYA	12	3214030012	SUKAMULYA	2
13	32.14.08.2013	PASANGGRA-HAN	13	3214030013	PASANGGRA-HAN	2

Catatan :
*) 1. Perkotaan
2. Perdesaan

https://jabar.bps.go.id

PROVINSI : [32] JAWA BARAT
KABUPATEN : [14] PURWAKARTA
KECAMATAN : [040] PLERED

Data Kemendagri			MFD 2021 Semester 2			
No	Kode	Nama Desa	No	Kode	Nama Desa	Status*
1	32.14.04.2008	RAWASARI	1	3214040001	RAWASARI	1
2	32.14.04.2005	GANDASOLI	2	3214040002	GANDASOLI	2
3	32.14.04.2012	GANDAMEKAR	3	3214040003	GANDAMEKAR	2
4	32.14.04.2003	CIBOGOHILIR	4	3214040004	CIBOGOHILIR	1
5	32.14.04.2002	PALINGGIHAN	5	3214040005	PALINGGIHAN	1
6	32.14.04.2011	BABAKANSARI	6	3214040006	BABAKAN SARI	1
7	32.14.04.2001	PLERED	7	3214040007	PLERED	1
8	32.14.04.2010	SINDANGSARI	8	3214040008	SINDANGSARI	1
9	32.14.04.2006	CITEKO	9	3214040009	CITEKO	1
10	32.14.04.2013	CITEKOKALER	10	3214040010	CITEKOKALER	1
11	32.14.04.2004	LINGGASARI	11	3214040011	LINGGASARI	1
12	32.14.04.2014	PAMOYANAN	12	3214040012	PAMOYANAN	1
13	32.14.04.2007	LIUNGGU-NUNG	13	3214040013	LIUNGGU-NUNG	2
14	32.14.04.2009	ANJUN	14	3214040014	ANJUN	1
15	32.14.04.2016	CIBOGO GI-RANG	15	3214040015	CIBOGO GI-RANG	1
16	32.14.04.2015	SEMPUR	16	3214040016	SEMPUR	1

Catatan :
*) 1. Perkotaan
2. Perdesaan

https://jabar.bps.go.id

DAFTAR DESA/KELURAHAN

PROVINSI : [32] JAWA BARAT
KABUPATEN : [14] PURWAKARTA
KECAMATAN : [050] SUKATANI

Data Kemendagri			MFD 2021 Semester 2			
No	Kode	Nama Desa	No	Kode	Nama Desa	Status*
1	32.14.05.2007	CIANTING	1	3214050002	CIANTING	2
2	32.14.05.2008	PASIRMUNJUL	2	3214050003	PASIRMUNJUL	2
3	32.14.05.2010	CIBODAS	3	3214050004	CIBODAS	2
4	32.14.05.2006	CIANTING UTARA	4	3214050005	CIANTING UTARA	1
5	32.14.05.2001	SUKATANI	5	3214050006	SUKATANI	1
6	32.14.05.2002	MALANGNEN-GAH	6	3214050007	MALANGNEN-GAH	1
7	32.14.05.2003	CILALAWI	7	3214050008	CILALAWI	1
8	32.14.05.2004	SUKAMAJU	8	3214050009	SUKAMAJU	2
9	32.14.05.2005	CIPICUNG	9	3214050010	CIPICUNG	2
10	32.14.05.2009	TANJURSIN-DANG	10	3214050011	TANJURSIN-DANG	2
11	32.14.05.2014	SINDANGLAYA	11	3214050012	SINDANGLAYA	2
12	32.14.05.2013	PANYIN DANGAN	12	3214050013	PANYIN DANGAN	2
13	32.14.05.2012	SUKAJAYA	13	3214050014	SUKAJAYA	1
14	32.14.05.2011	CIJANTUNG	14	3214050015	CIJANTUNG	1

Catatan :
*) 1. Perkotaan
2. Perdesaan

https://jabar.bps.go.id

PROVINSI : [32] JAWA BARAT
KABUPATEN : [14] PURWAKARTA
KECAMATAN : [060] DARANGDAN

Data Kemendagri			MFD 2021 Semester 2			
No	Kode	Nama Desa	No	Kode	Nama Desa	Status*
1	32.14.06.2010	PASIRANGIN	1	3214060001	PASIRANGIN	2
2	32.14.06.2004	NANGEWER	2	3214060002	NANGEWER	2
3	32.14.06.2014	NEGLASARI	3	3214060003	NEGLASARI	2
4	32.14.06.2006	LINGGARSARI	4	3214060004	LINGGASARI	2
5	32.14.06.2007	SAWIT	5	3214060005	SAWIT	1
6	32.14.06.2012	SIRNAMANAH	6	3214060006	SIRNAMANAH	2
7	32.14.06.2002	DEPOK	7	3214060007	DEPOK	2
8	32.14.06.2011	LEGOKSARI	8	3214060008	LEGOKSARI	2
9	32.14.06.2005	MEKARSARI	9	3214060009	MEKARSARI	2
10	32.14.06.2009	GUNUNGHEJO	10	3214060012	GUNUNGHEJO	2
11	32.14.06.2001	DARANGDAN	11	3214060013	DARANGDAN	1
12	32.14.06.2013	SADARKARYA	12	3214060014	SADARKARYA	2
13	32.14.06.2008	LINGGAMUKTI	13	3214060015	LINGGAMUKTI	2
14	32.14.06.2003	CILINGGA	14	3214060016	CILINGGA	2
15	32.14.06.2015	NAGRAK	15	3214060017	NAGRAK	2

Catatan :
*) 1. Perkotaan
2. Perdesaan

https://jabar.bps.go.id

DAFTAR DESA/KELURAHAN

PROVINSI : [32] JAWA BARAT
KABUPATEN : [14] PURWAKARTA
KECAMATAN : [070] BOJONG

Data Kemendagri			MFD 2021 Semester 2			
No	Kode	Nama Desa	No	Kode	Nama Desa	Status*
1	32.14.11.2007	CIBINGBIN	1	3214070001	CIBINGBIN	2
2	32.14.11.2002	BOJONG TIMUR	2	3214070002	BOJONG TIMUR	2
3	32.14.11.2014	PASANGGRA-HAN	3	3214070003	PASANGGRA-HAN	2
4	32.14.11.2004	CIHANJAWAR	4	3214070004	CIHANJAWAR	2
5	32.14.11.2003	CIKERIS	5	3214070005	CIKERIS	1
6	32.14.11.2001	BOJONG BARAT	6	3214070006	BOJONG BARAT	1
7	32.14.11.2009	PANGKALAN	7	3214070007	PANGKALAN	2
8	32.14.11.2011	SUKAMANAH	8	3214070008	SUKAMANAH	2
9	32.14.11.2010	PAWENANG	9	3214070009	PAWENANG	2
10	32.14.11.2013	SINDANGSARI	10	3214070010	SINDANGSARI	2
11	32.14.11.2012	SINDANG-PANON	11	3214070011	SINDANG-PANON	2
12	32.14.11.2005	CIPEUNDEUY	12	3214070012	CIPEUNDEUY	2
13	32.14.11.2006	CILEUNCA	13	3214070013	CILEUNCA	2
14	32.14.11.2008	KERTASARI	14	3214070014	KERTASARI	2

Catatan :
*) 1. Perkotaan
2. Perdesaan

https://jabar.bps.go.id

PROVINSI : [32] JAWA BARAT
KABUPATEN : [14] PURWAKARTA
KECAMATAN : [080] WANAYASA

Data Kemendagri			MFD 2021 Semester 2			
No	Kode	Nama Desa	No	Kode	Nama Desa	Status*
1	32.14.09.2008	NANGERANG	1	3214080001	NANGERANG	1
2	32.14.09.2004	SIMPANG	2	3214080002	SIMPANG	2
3	32.14.09.2012	SAKAMBANG	3	3214080003	SAKAMBANG	2
4	32.14.09.2005	NAGROG	4	3214080004	NAGROG	2
5	32.14.09.2006	CIBUNTU	5	3214080005	CIBUNTU	1
6	32.14.09.2010	SUMURUGUL	6	3214080006	SUMURUGUL	1
7	32.14.09.2011	RAHARJA	7	3214080007	RAHARJA	1
8	32.14.09.2001	WANAYASA	8	3214080008	WANAYASA	1
9	32.14.09.2007	BABAKAN	9	3214080009	BABAKAN	1
10	32.14.09.2003	WANASARI	10	3214080016	WANASARI	1
11	32.14.09.2014	LEGOKHUNI	11	3214080017	LEGOKHUNI	2
12	32.14.09.2009	CIAWI	12	3214080018	CIAWI	2
13	32.14.09.2002	SUKADAMI	13	3214080019	SUKADAMI	2
14	32.14.09.2013	TARINGGUL TONGGOH	14	3214080020	TARINGGUL TONGGOH	2
15	32.14.09.2015	TARINGGUL TENGAH	15	3214080021	TARINGGUL TENGAH	2

Catatan :
*) 1. Perkotaan
2. Perdesaan

https://jabar.bps.go.id

DAFTAR DESA/KELURAHAN

PROVINSI : [32] JAWA BARAT
KABUPATEN : [14] PURWAKARTA
KECAMATAN : [081] KIARAPEDES

Data Kemendagri			MFD 2021 Semester 2			
No	Kode	Nama Desa	No	Kode	Nama Desa	Status*
1	32.14.17.2009	PUSAKAMULYA	1	3214081001	PUSAKAMULYA	2
2	32.14.17.2003	PARAKAN GAROKGEK	2	3214081002	PARAKAN GAROKGEK	2
3	32.14.17.2002	CIRACAS	3	3214081003	CIRACAS	2
4	32.14.17.2001	KARANGPE-DAS	4	3214081004	KIARAPEDES	2
5	32.14.17.2008	CIBEBER	5	3214081005	CIBEBER	1
6	32.14.17.2010	SUMBERSARI	6	3214081006	SUMBERSARI	2
7	32.14.17.2005	MEKARJAYA	7	3214081007	MEKARJAYA	2
8	32.14.17.2006	MARGALUYU	8	3214081008	MARGALUYU	2
9	32.14.17.2007	GARDU	9	3214081009	GARDU	2
10	32.14.17.2004	TARINGGUL-LANDEUH	10	3214081010	TARINGGUL LANDEUH	2

Catatan :
*) 1. Perkotaan
2. Perdesaan

https://jabar.bps.go.id

PROVINSI : [32] JAWA BARAT
KABUPATEN : [14] PURWAKARTA
KECAMATAN : [090] PASAWAHAN

Data Kemendagri			MFD 2021 Semester 2			
No	Kode	Nama Desa	No	Kode	Nama Desa	Status*
1	32.14.10.2004	CIHERANG	1	3214090009	CIHERANG	1
2	32.14.10.2005	CIDAHU	2	3214090010	CIDAHU	2
3	32.14.10.2001	PASAWAHAN-ANYAR	3	3214090011	PASAWAHAN ANYAR	1
4	32.14.10.2006	PASAWAHAN KIDUL	4	3214090012	PASAWAHAN KIDUL	1
5	32.14.10.2003	SAWAHKULON	5	3214090013	SAWAH KULON	1
6	32.14.10.2007	KERTAJAYA	6	3214090014	KERTAJAYA	1
7	32.14.10.2008	LEBAKANYAR	7	3214090015	LEBAKANYAR	1
8	32.14.10.2012	CIHUNI	8	3214090016	CIHUNI	1
9	32.14.10.2011	WARUNG KADU	9	3214090017	WARUNG KADU	1
10	32.14.10.2009	SELAAWI	10	3214090018	SELAAWI	1
11	32.14.10.2010	MARGASARI	11	3214090019	MARGASARI	1
12	32.14.10.2002	PASAWAHAN	12	3214090020	PASAWAHAN	1

Catatan :
*) 1. Perkotaan
2. Perdesaan

https://jabar.bps.go.id

DAFTAR DESA/KELURAHAN

PROVINSI : [32] JAWA BARAT
KABUPATEN : [14] PURWAKARTA
KECAMATAN : [091] PONDOK SALAM

Data Kemendagri			MFD 2021 Semester 2			
No	Kode	Nama Desa	No	Kode	Nama Desa	Status*
1	32.14.16.2008	BUNGURJAYA	1	3214091001	BUNGUR JAYA	2
2	32.14.16.2002	PONDOK BUNGUR	2	3214091002	PONDOK BUNGUR	2
3	32.14.16.2003	SALEM	3	3214091003	SALEM	2
4	32.14.16.2004	GALUDRA	4	3214091004	GALUDRA	2
5	32.14.16.2010	SUKAJADI	5	3214091005	SUKAJADI	2
6	32.14.16.2005	TANJUNGSARI	6	3214091006	TANJUNGSARI	2
7	32.14.16.2007	SALAM JAYA	7	3214091007	SALAM JAYA	2
8	32.14.16.2011	SITU	8	3214091008	SITU	2
9	32.14.16.2001	PARAKAN-SALAM	9	3214091009	PARAKAN-SALAM	2
10	32.14.16.2006	SALAM MULYA	10	3214091010	SALAMMULYA	2
11	32.14.16.2009	GURUDUG	11	3214091011	GURUDUG	2

Catatan :
*) 1. Perkotaan
2. Perdesaan

https://jabar.bps.go.id

PROVINSI : [32] JAWA BARAT
KABUPATEN : [14] PURWAKARTA
KECAMATAN : [100] PURWAKARTA

Data Kemendagri			MFD 2021 Semester 2			
No	Kode	Nama Kelurahan	No	Kode	Nama Kelurahan	Status*
1	32.14.01.1004	SINDANGKASIH	1	3214100005	SINDANGKASIH	1
2	32.14.01.1001	NAGRI KIDUL	2	3214100006	NAGERI KIDUL	1
3	32.14.01.1003	NAGRI TENGAH	3	3214100007	NAGERI TENGAH	1
4	32.14.01.1005	CIPAISAN	4	3214100008	CIPAISAN	1
5	32.14.01.1002	NAGRI KALER	5	3214100009	NAGERI KALER	1
6	32.14.01.1008	TEGALMUNCUL	6	3214100010	TEGALMUNJUL	1
7	32.14.01.2010	CITALANG	7	3214100011	CITALANG	1
8	32.14.01.1009	MUNJULJAYA	8	3214100012	MUNJULJAYA	1
9	32.14.01.1007	CISEUREUH	9	3214100013	CISEUREUH	1
10	32.14.01.1006	PURWAMEKAR	10	3214100016	PURWAMEKAR	1

https://jabar.bps.go.id

Catatan :
*) 1. Perkotaan
2. Perdesaan

DAFTAR DESA/KELURAHAN

PROVINSI : [32] JAWA BARAT
KABUPATEN : [14] PURWAKARTA
KECAMATAN : [101] BABAKANCIKAO

Data Kemendagri			MFD 2021 Semester 2			
No	Kode	Nama Desa	No	Kode	Nama Desa	Status*
1	32.14.12.2006	MARACANG	1	3214101001	MARACANG	1
2	32.14.12.2007	CIWARENG	2	3214101002	CIWARENG	1
3	32.14.12.2008	MULYAMEKAR	3	3214101003	MULYAMEKAR	1
4	32.14.12.2009	CIGELAM	4	3214101004	CIGELAM	2
5	32.14.12.2004	BABAKAN CIKAO	5	3214101005	BABAKAN CIKAO	1
6	32.14.12.2005	KADUMEKAR	6	3214101006	KADUMEKAR	2
7	32.14.12.2003	HEGARMANAH	7	3214101007	HEGARMANAH	1
8	32.14.12.2002	CICADAS	8	3214101008	CICADAS	2
9	32.14.12.2001	CILANGKAP	9	3214101009	CILANGKAP	2

Catatan :
*) 1. Perkotaan
2. Perdesaan

https://jabar.bps.go.id

PROVINSI : [32] JAWA BARAT
KABUPATEN : [14] PURWAKARTA
KECAMATAN : [110] CAMPAKA

Data Kemendagri			MFD 2021 Semester 2			
No	Kode	Nama Desa	No	Kode	Nama Desa	Status*
1	32.14.02.2004	CIRENDE	1	3214110001	CIRENDE	2
2	32.14.02.2003	BENTENG	2	3214110010	BENTENG	2
3	32.14.02.2001	CAMPAKA	3	3214110011	CAMPAKA	1
4	32.14.02.2002	CAMPAKASARI	4	3214110012	CAMPAKASARI	1
5	32.14.02.2009	CIJUNTI	5	3214110023	CIJUNTI	2
6	32.14.02.2010	CISAAT	6	3214110024	CISAAT	2
7	32.14.02.2008	CIMAHI	7	3214110025	CIMAHI	2
8	32.14.02.2005	CIKUMPAY	8	3214110026	CIKUMPAY	1
9	32.14.02.2006	CIJAYA	9	3214110027	CIJAYA	2
10	32.14.02.2007	KERTAMUKTI	10	3214110028	KERTAMUKTI	2

https://jabar.bps.go.id

Catatan :
*) 1. Perkotaan
2. Perdesaan

DAFTAR DESA/KELURAHAN

PROVINSI : [32] JAWA BARAT
KABUPATEN : [14] PURWAKARTA
KECAMATAN : [111] CIBATU

Data Kemendagri			MFD 2021 Semester 2			
No	Kode	Nama Desa	No	Kode	Nama Desa	Status*
1	32.14.14.2009	WANAWALI	1	3214111001	WANAWALI	2
2	32.14.14.2007	CIKADU	2	3214111002	CIKADU	2
3	32.14.14.2008	CIBUKA-MANAH	3	3214111003	CIBUKA-MANAH	2
4	32.14.14.2006	CIRANGKONG	4	3214111004	CIRANGKONG	2
5	32.14.14.2010	CIPANCUR	5	3214111005	CIPANCUR	2
6	32.14.14.2004	CIPINANG	6	3214111006	CIPINANG	1
7	32.14.14.2005	CIPARUNGSARI	7	3214111007	CIPARUNGSARI	2
8	32.14.14.2003	KARYAMEKAR	8	3214111008	KARYAMEKAR	2
9	32.14.14.2001	CIBATU	9	3214111009	CIBATU	2
10	32.14.14.2002	CILANDAK	10	3214111010	CILANDAK	2

https://jabar.bps.go.id

Catatan :
*) 1. Perkotaan
2. Perdesaan

PROVINSI : [32] JAWA BARAT
KABUPATEN : [14] PURWAKARTA
KECAMATAN : [112] BUNGURSARI

Data Kemendagri			MFD 2021 Semester 2			
No	Kode	Nama Desa	No	Kode	Nama Desa	Status*
1	32.14.13.2001	CIWANGI	1	3214112001	CIWANGI	1
2	32.14.13.2002	CIBEUNING	2	3214112002	CIBEUNING	1
3	32.14.13.2003	BUNGURSARI	3	3214112003	BUNGURSARI	1
4	32.14.13.2005	CIBUNGUR	4	3214112004	CIBUNGUR	1
5	32.14.13.2004	DANGDEUR	5	3214112005	DANGDEUR	2
6	32.14.13.2006	WANAKERTA	6	3214112006	WANAKERTA	2
7	32.14.13.2007	CINANGKA	7	3214112007	CINANGKA	1
8	32.14.13.2008	CIKOPO	8	3214112008	CIKOPO	1
9	32.14.13.2010	KARANGMUKTI	9	3214112009	KARANGMUKTI	2
10	32.14.13.2009	CIBODAS	10	3214112010	CIBODAS	2

Catatan :
*) 1. Perkotaan
2. Perdesaan

https://jabar.bps.go.id

https://jabar.bps.go.id

KABUPATEN KARAWANG

https://jabar.bps.go.id

https://jabar.bps.go.id

PROVINSI : [32] JAWA BARAT
KABUPATEN : [15] KARAWANG

Data Kemendagri			MFD 2021 Semester 2		
No	Kode	Nama Kecamatan	No	Kode	Nama Kecamatan
1	32.15.02	PANGKALAN	1	3215010	PANGKALAN
2	32.15.28	TEGALWARU	2	3215011	TEGALWARU
3	32.15.04	CIAMPEL	3	3215020	CIAMPEL
4	32.15.03	TELUKJAMBE TIMUR	4	3215031	TELUKJAMBE TIMUR
5	32.15.27	TELUKJAMBE BARAT	5	3215032	TELUKJAMBE BARAT
6	32.15.05	KLARI	6	3215040	KLARI
7	32.15.13	CIKAMPEK	7	3215050	CIKAMPEK
8	32.15.29	PURWASARI	8	3215051	PURWASARI
9	32.15.16	TIRTAMULYA	9	3215060	TIRTAMULYA
10	32.15.14	JATISARI	10	3215070	JATISARI
11	32.15.24	BANYUSARI	11	3215071	BANYUSARI
12	32.15.25	KOTA BARU	12	3215072	KOTABARU
13	32.15.15	CILAMAYA WETAN	13	3215081	CILAMAYA WETAN
14	32.15.23	CILAMAYA KULON	14	3215082	CILAMAYA KULON
15	32.15.19	LEMAHABANG	15	3215090	LEMAHABANG
16	32.15.17	TELAGASARI	16	3215100	TELAGASARI
17	32.15.21	MAJALAYA	17	3215111	MAJALAYA
18	32.15.26	KARAWANG TIMUR	18	3215112	KARAWANG TIMUR
19	32.15.01	KARAWANG BARAT	19	3215113	KARAWANG BARAT
20	32.15.18	RAWAMERTA	20	3215120	RAWAMERTA

https://jabar.bps.go.id

DAFTAR KECAMATAN

PROVINSI : [32] JAWA BARAT
KABUPATEN : [15] KARAWANG

Data Kemendagri			MFD 2021 Semester 2		
No	Kode	Nama Kecamatan	No	Kode	Nama Kecamatan
21	32.15.20	TEMPURAN	21	3215130	TEMPURAN
22	32.15.07	KUTAWALUYA	22	3215140	KUTAWALUYA
23	32.15.06	RENGASDENGKLOK	23	3215150	RENGASDENGKLOK
24	32.15.22	JAYAKERTA	24	3215151	JAYAKERTA
25	32.15.10	PEDES	25	3215160	PEDES
26	32.15.30	CILEBAR	26	3215161	CILEBAR
27	32.15.11	CIBUAYA	27	3215170	CIBUAYA
28	32.15.09	TIRTAJAYA	28	3215180	TIRTAJAYA
29	32.15.08	BATUJAYA	29	3215190	BATUJAYA
30	32.15.12	PAKISJAYA	30	3215200	PAKISJAYA

https://jabar.bps.go.id

JUMLAH DESA/KELURAHAN PER KECAMATAN

PROVINSI : [32] JAWA BARAT
KABUPATEN : [15] KARAWANG

Data Kemendagri				MFD 2021 Semester 2			
No	Kode	Nama Kecamatan	Jml Desa	No	Kode	Nama Kecamatan	Jml Desa
1	32.15.02	PANGKALAN	8	1	3215010	PANGKALAN	8
2	32.15.28	TEGALWARU	9	2	3215011	TEGALWARU	9
3	32.15.04	CIAMPEL	7	3	3215020	CIAMPEL	7
4	32.15.03	TELUKJAMBE TIMUR	9	4	3215031	TELUKJAMBE TIMUR	9
5	32.15.27	TELUKJAMBE BARAT	10	5	3215032	TELUKJAMBE BARAT	10
6	32.15.05	KLARI	13	6	3215040	KLARI	13
7	32.15.13	CIKAMPEK	10	7	3215050	CIKAMPEK	10
8	32.15.29	PURWASARI	8	8	3215051	PURWASARI	8
9	32.15.16	TIRTAMULYA	10	9	3215060	TIRTAMULYA	10
10	32.15.14	JATISARI	14	10	3215070	JATISARI	14
11	32.15.24	BANYUSARI	12	11	3215071	BANYUSARI	12
12	32.15.25	KOTA BARU	9	12	3215072	KOTABARU	9
13	32.15.15	CILAMAYA WETAN	12	13	3215081	CILAMAYA WETAN	12
14	32.15.23	CILAMAYA KULON	12	14	3215082	CILAMAYA KULON	12
15	32.15.19	LEMAHABANG	11	15	3215090	LEMAHABANG	11
16	32.15.17	TELAGASARI	14	16	3215100	TELAGASARI	14
17	32.15.21	MAJALAYA	7	17	3215111	MAJALAYA	7
18	32.15.26	KARAWANG TIMUR	8	18	3215112	KARAWANG TIMUR	8
19	32.15.01	KARAWANG BARAT	8	19	3215113	KARAWANG BARAT	8
20	32.15.18	RAWAMERTA	13	20	3215120	RAWAMERTA	13

https://jabar.bps.go.id

JUMLAH DESA/KELURAHAN PER KECAMATAN

PROVINSI : [32] JAWA BARAT
KABUPATEN : [15] KARAWANG

Data Kemendagri				MFD 2021 Semester 2			
No	Kode	Nama Kecamatan	Jml Desa	No	Kode	Nama Kecamatan	Jml Desa
21	32.15.20	TEMPURAN	14	21	3215130	TEMPURAN	14
22	32.15.07	KUTAWALUYA	12	22	3215140	KUTAWALUYA	12
23	32.15.06	RENGAS-DENGKLOK	9	23	3215150	RENGAS-DENGKLOK	9
24	32.15.22	JAYAKERTA	8	24	3215151	JAYAKERTA	8
25	32.15.10	PEDES	12	25	3215160	PEDES	12
26	32.15.30	CILEBAR	10	26	3215161	CILEBAR	10
27	32.15.11	CIBUAYA	11	27	3215170	CIBUAYA	11
28	32.15.09	TIRTAJAYA	11	28	3215180	TIRTAJAYA	11
29	32.15.08	BATUJAYA	10	29	3215190	BATUJAYA	10
30	32.15.12	PAKISJAYA	8	30	3215200	PAKISJAYA	8

https://jabar.bps.go.id

PROVINSI : [32] JAWA BARAT
KABUPATEN : [15] KARAWANG
KECAMATAN : [010] PANGKALAN

Data Kemendagri			MFD 2021 Semester 2			
No	Kode	Nama Desa	No	Kode	Nama Desa	Status*
1	32.15.02.2008	MEDALSARI	1	3215010001	MEDALSARI	2
2	32.15.02.2006	KERTASARI	2	3215010011	KERTASARI	2
3	32.15.02.2005	CINTAASIH	3	3215010012	CINTAASIH	2
4	32.15.02.2007	MULANGSARI	4	3215010013	MULANGSARI	2
5	32.15.02.2004	JATILAKSANA	5	3215010014	JATILAKSANA	2
6	32.15.02.2001	CIPTASARI	6	3215010015	CIPTASARI	2
7	32.15.02.2003	TAMANSARI	7	3215010016	TAMANSARI	2
8	32.15.02.2002	TAMANMEKAR	8	3215010017	TAMANMEKAR	2

Catatan :
*) 1. Perkotaan
2. Perdesaan

https://jabar.bps.go.id

DAFTAR DESA/KELURAHAN

PROVINSI : [32] JAWA BARAT
KABUPATEN : [15] KARAWANG
KECAMATAN : [011] TEGALWARU

Data Kemendagri			MFD 2021 Semester 2			
No	Kode	Nama Desa	No	Kode	Nama Desa	Status*
1	32.15.28.2009	CIPURWASARI	1	3215011001	CIPURWASARI	2
2	32.15.28.2001	CIGUNUNG-SARI	2	3215011002	CIGUNUNG-SARI	2
3	32.15.28.2003	MEKARBUANA	3	3215011003	MEKARBUANA	2
4	32.15.28.2002	WARGASETRA	4	3215011004	WARGASETRA	2
5	32.15.28.2004	CINTALAKSA-NA	5	3215011005	CINTALAKSA-NA	2
6	32.15.28.2005	CINTAWARGI	6	3215011006	CINTAWARGI	1
7	32.15.28.2006	CINTA-LANGGENG	7	3215011007	CINTA-LANGGENG	2
8	32.15.28.2008	KUTAMANEUH	8	3215011008	KUTAMANEUH	2
9	32.15.28.2007	KUTA-LANGGENG	9	3215011009	KUTA-LANGGENG	2

https://jabar.bps.go.id

Catatan :
*) 1. Perkotaan
2. Perdesaan

PROVINSI : [32] JAWA BARAT
KABUPATEN : [15] KARAWANG
KECAMATAN : [020] CIAMPEL

Data Kemendagri			MFD 2021 Semester 2			
No	Kode	Nama Desa	No	Kode	Nama Desa	Status*
1	32.15.04.2008	TEGALLEGA	1	3215020001	TEGALLEGA	2
2	32.15.04.2007	MULYASEJATI	2	3215020002	MULYASEJATI	2
3	32.15.04.2006	MULYASARI	3	3215020003	MULYASARI	2
4	32.15.04.2005	KUTANEGARA	4	3215020004	KUTANEGARA	2
5	32.15.04.2001	KUTAPOHACI	5	3215020005	KUTAPOHACI	1
6	32.15.04.2004	KUTAMEKAR	6	3215020006	KUTAMEKAR	1
7	32.15.04.2003	PARUNG MULYA	7	3215020007	PARUNG MULYA	1

Catatan :
*) 1. Perkotaan
2. Perdesaan

https://jabar.bps.go.id

DAFTAR DESA/KELURAHAN

PROVINSI : [32] JAWA BARAT
KABUPATEN : [15] KARAWANG
KECAMATAN : [031] TELUKJAMBE TIMUR

Data Kemendagri			MFD 2021 Semester 2			
No	Kode	Nama Desa	No	Kode	Nama Desa	Status*
1	32.15.03.2003	SIRNABAYA	1	3215031001	SIRNABAYA	1
2	32.15.03.2019	PINAYUNGAN	2	3215031002	PINAYUNGAN	1
3	32.15.03.2001	TELUKJAMBE	3	3215031003	TELUKJAMBE	1
4	32.15.03.2004	PUSEURJAYA	4	3215031004	PUSEURJAYA	1
5	32.15.03.2005	SUKALUYU	5	3215031005	SUKALUYU	1
6	32.15.03.2002	SUKAHARJA	6	3215031006	SUKAHARJA	1
7	32.15.03.2006	WADAS	7	3215031007	WADAS	1
8	32.15.03.2012	SUKAMAKMUR	8	3215031008	SUKAMAKMUR	1
9	32.15.03.2011	PURWADANA	9	3215031009	PURWADANA	1

Catatan :
*) 1. Perkotaan
2. Perdesaan

https://jabar.bps.go.id

PROVINSI : [32] JAWA BARAT
KABUPATEN : [15] KARAWANG
KECAMATAN : [032] TELUKJAMBE BARAT

Data Kemendagri			MFD 2021 Semester 2			
No	Kode	Nama Desa	No	Kode	Nama Desa	Status*
1	32.15.27.2009	WANAJAYA	1	3215032001	WANAJAYA	2
2	32.15.27.2008	WANAKERTA	2	3215032002	WANAKERTA	2
3	32.15.27.2007	WANASARI	3	3215032003	WANASARI	2
4	32.15.27.2002	MARGAMULYA	4	3215032004	MARGAMULYA	2
5	32.15.27.2001	MARGAKAYA	5	3215032005	MARGAKAYA	1
6	32.15.27.2003	KARANGLIGAR	6	3215032006	KARANGLIGAR	2
7	32.15.27.2006	KARANG MULYA	7	3215032007	KARANG MULYA	1
8	32.15.27.2010	MULYAJAYA	8	3215032008	MULYAJAYA	2
9	32.15.27.2004	MEKARMULYA	9	3215032009	MEKARMULYA	2
10	32.15.27.2005	PARUNGSARI	10	3215032010	PARUNGSARI	2

https://jabar.bps.go.id

Catatan :
*) 1. Perkotaan
2. Perdesaan

DAFTAR DESA/KELURAHAN

PROVINSI : [32] JAWA BARAT
KABUPATEN : [15] KARAWANG
KECAMATAN : [040] KLARI

Data Kemendagri			MFD 2021 Semester 2			
No	Kode	Nama Desa	No	Kode	Nama Desa	Status*
1	32.15.05.2019	KARANG ANYAR	1	3215040001	KARANG ANYAR	2
2	32.15.05.2018	CURUG	2	3215040002	CURUG	1
3	32.15.05.2020	CIMAHI	3	3215040003	CIMAHI	1
4	32.15.05.2005	SUMURKON-DANG	4	3215040004	SUMURKON-DANG	1
5	32.15.05.2003	WALAHAR	5	3215040005	WALAHAR	1
6	32.15.05.2004	KIARAPAYUNG	6	3215040006	KIARAPAYUNG	1
7	32.15.05.2017	GINTUNGKER-TA	7	3215040007	GINTUNGKER-TA	1
8	32.15.05.2016	ANGGADITA	8	3215040008	ANGGADITA	1
9	32.15.05.2007	KLARI	9	3215040011	KLARI	1
10	32.15.05.2006	CIBOLANGSARI	10	3215040012	CIBOLANGSARI	1
11	32.15.05.2001	DUREN	11	3215040013	DUREN	1
12	32.15.05.2002	PANCAWATI	12	3215040014	PANCAWATI	1
13	32.15.05.2008	BELENDUNG	13	3215040016	BELENDUNG	1

Catatan :
*) 1. Perkotaan
2. Perdesaan

https://jabar.bps.go.id

PROVINSI : [32] JAWA BARAT
KABUPATEN : [15] KARAWANG
KECAMATAN : [050] CIKAMPEK

Data Kemendagri			MFD 2021 Semester 2			
No	Kode	Nama Desa	No	Kode	Nama Desa	Status*
1	32.15.13.2002	KALIHURIP	1	3215050001	KALIHURIP	1
2	32.15.13.2010	KAMOJING	2	3215050002	KAMOJING	1
3	32.15.13.2009	CIKAMPEK TIMUR	3	3215050006	CIKAMPEK TIMUR	1
4	32.15.13.2007	CIKAMPEK PUSAKA	4	3215050007	CIKAMPEK PUSAKA	1
5	32.15.13.2006	CIKAMPEK SELATAN	5	3215050008	CIKAMPEK SELATAN	1
6	32.15.13.2003	CIKAMPEK KOTA	6	3215050009	CIKAMPEK KOTA	1
7	32.15.13.2008	CIKAMPEK BARAT	7	3215050011	CIKAMPEK BARAT	1
8	32.15.13.2001	DAWUAN TIMUR	8	3215050012	DAWUAN TIMUR	1
9	32.15.13.2004	DAWUAN TENGAH	9	3215050013	DAWUAN TENGAH	1
10	32.15.13.2011	DAWUAN BARAT	10	3215050014	DAWUAN BARAT	1

https://jabar.bps.go.id

Catatan :
*) 1. Perkotaan
2. Perdesaan

DAFTAR DESA/KELURAHAN

PROVINSI : [32] JAWA BARAT
KABUPATEN : [15] KARAWANG
KECAMATAN : [051] PURWASARI

Data Kemendagri			MFD 2021 Semester 2			
No	Kode	Nama Desa	No	Kode	Nama Desa	Status*
1	32.15.29.2004	MEKARJAYA	1	3215051001	MEKARJAYA	1
2	32.15.29.2005	TAMELANG	2	3215051002	TAMELANG	1
3	32.15.29.2003	PURWASARI	3	3215051003	PURWASARI	1
4	32.15.29.2007	SUKASARI	4	3215051004	SUKASARI	1
5	32.15.29.2002	TEGALSARI	5	3215051005	TEGALSARI	1
6	32.15.29.2008	KARANGSARI	6	3215051006	KARANGSARI	1
7	32.15.29.2001	DARAWOLONG	7	3215051007	DARAWOLONG	2
8	32.15.29.2006	CENGKONG	8	3215051008	CENGKONG	1

Catatan :
*) 1. Perkotaan
2. Perdesaan

https://jabar.bps.go.id

PROVINSI : [32] JAWA BARAT
KABUPATEN : [15] KARAWANG
KECAMATAN : [060] TIRTAMULYA

Data Kemendagri			MFD 2021 Semester 2			
No	Kode	Nama Desa	No	Kode	Nama Desa	Status*
1	32.15.16.2002	KARANG-SINOM	1	3215060002	KARANG-SINOM	2
2	32.15.16.2003	KARANGJAYA	2	3215060003	KARANGJAYA	1
3	32.15.16.2005	PARAKAN MULYA	3	3215060004	PARAKAN MULYA	2
4	32.15.16.2001	CITARIK	4	3215060005	CITARIK	2
5	32.15.16.2010	TIRTASARI	5	3215060006	TIRTASARI	2
6	32.15.16.2004	PARAKAN	6	3215060007	PARAKAN	2
7	32.15.16.2006	KAMURANG	7	3215060008	KAMURANG	2
8	32.15.16.2009	BOJONGSARI	8	3215060009	BOJONGSARI	2
9	32.15.16.2007	CIPONDOH	9	3215060010	CIPONDOH	2
10	32.15.16.2008	KERTAMULYA	10	3215060011	KERTAMULYA	2

https://jabar.bps.go.id

Catatan :
*) 1. Perkotaan
2. Perdesaan

DAFTAR DESA/KELURAHAN

PROVINSI : [32] JAWA BARAT
KABUPATEN : [15] KARAWANG
KECAMATAN : [070] JATISARI

Data Kemendagri			MFD 2021 Semester 2			
No	Kode	Nama Desa	No	Kode	Nama Desa	Status*
1	32.15.24.2012	BARUGBUG	1	3215070004	BARUGBUG	2
2	32.15.24.2009	SITUDAM	2	3215070005	SITUDAM	2
3	32.15.24.2008	BALONGGAN-DU	3	3215070006	BALONGGAN-DU	1
4	32.15.24.2007	KALIJATI	4	3215070009	KALIJATI	2
5	32.15.24.2003	MEKARSARI	5	3215070010	MEKARSARI	1
6	32.15.24.2002	JATISARI	6	3215070011	JATISARI	1
7	32.15.24.2001	CIREJAG	7	3215070012	CIREJAG	1
8	32.15.24.2010	CIKALONGSARI	8	3215070013	CIKALONGSARI	1
9	32.15.24.2004	JATIRAGAS	9	3215070014	JATIRAGAS	1
10	32.15.24.2011	JATIWANGI	10	3215070015	JATIWANGI	1
11	32.15.24.2006	JATIBARU	11	3215070016	JATIBARU	2
12	32.15.24.2005	TELARSARI	12	3215070017	TELARSARI	1
13	32.15.14.2013	SUKAMEKAR	13	3215070018	SUKAMEKAR	2
14	32.15.14.2014	PACING	14	3215070019	PACING	2

Catatan :
*) 1. Perkotaan
2. Perdesaan

https://jabar.bps.go.id

PROVINSI : [32] JAWA BARAT
KABUPATEN : [15] KARAWANG
KECAMATAN : [071] BANYUSARI

Data Kemendagri			MFD 2021 Semester 2			
No	Kode	Nama Desa	No	Kode	Nama Desa	Status*
1	32.15.24.2001	GEMBONGAN	1	3215071001	PAMEKARAN	1
2	32.15.24.2002	GEMPOL	2	3215071002	CICINDE SELA-TAN	1
3	32.15.24.2003	GEMPOL KOLOT	3	3215071003	CICINDE UTARA	1
4	32.15.24.2004	BANYUASIH	4	3215071004	JAYAMUKTI	1
5	32.15.24.2005	KERTAHARJA	5	3215071005	GEMPOLKO-LOT	1
6	32.15.24.2006	TANJUNG	6	3215071006	GEMPOL	1
7	32.15.26.2007	JAYAMUKTI	7	3215071007	GEMBONGAN	2
8	32.15.24.2008	CICINDE UTARA	8	3215071008	MEKARASIH	2
9	32.15.24.2009	CICINDE SELA-TAN	9	3215071009	BANYUASIH	2
10	32.15.24.2010	MEKARASIH	10	3215071010	TALUNJAYA	2
11	32.15.24.2011	TALUNJAYA	11	3215071011	TANJUNG	2
12	32.15.24.2012	PAMEKARAN	12	3215071012	KUTARAHARJA	2

Catatan :
*) 1. Perkotaan
2. Perdesaan

https://jabar.bps.go.id

DAFTAR DESA/KELURAHAN

PROVINSI : [32] JAWA BARAT
KABUPATEN : [15] KARAWANG
KECAMATAN : [072] KOTABARU

Data Kemendagri			MFD 2021 Semester 2			
No	Kode	Nama Desa	No	Kode	Nama Desa	Status*
1	32.15.25.2008	SARIMULYA	1	3215072001	SARIMULYA	1
2	32.15.25.2007	JOMIN BARAT	2	3215072002	JOMIN BARAT	1
3	32.15.25.2006	JOMIN TIMUR	3	3215072003	JOMIN TIMUR	1
4	32.15.25.2002	PANGULAH SELATAN	4	3215072004	PANGULAH SELATAN	1
5	32.15.25.2003	PANGULAH UTARA	5	3215072005	PANGULAH UTARA	1
6	32.15.25.2004	PANGULAH BARU	6	3215072006	PANGULAH BARU	2
7	32.15.25.2001	WANCIMEKAR	7	3215072007	WANCIMEKAR	1
8	32.15.25.2005	PUCUNG	8	3215072008	PUCUNG	1
9	32.15.25.2009	CIKAMPEK UTARA	9	3215072009	CIKAMPEK UTARA	1

Catatan :
*) 1. Perkotaan
2. Perdesaan

https://jabar.bps.go.id

PROVINSI : [32] JAWA BARAT
KABUPATEN : [15] KARAWANG
KECAMATAN : [081] CILAMAYA WETAN

Data Kemendagri			MFD 2021 Semester 2			
No	Kode	Nama Desa	No	Kode	Nama Desa	Status*
1	32.15.15.2009	CIKARANG	1	3215081001	CIKARANG	1
2	32.15.15.2008	CIKALONG	2	3215081002	CIKALONG	1
3	32.15.15.2007	TEGALSARI	3	3215081003	TEGALSARI	1
4	32.15.15.2006	TEGALWARU	4	3215081004	TEGALWARU	2
5	32.15.15.2001	MEKARMAYA	5	3215081005	MEKARMAYA	1
6	32.15.15.2002	CILAMAYA	6	3215081006	CILAMAYA	1
7	32.15.15.2005	SUKATANI	7	3215081007	SUKATANI	1
8	32.15.15.2012	SUKAKERTA	8	3215081008	SUKAKERTA	2
9	32.15.15.2011	RAWAGEMPOL KULON	9	3215081009	RAWAGEMPOL KULON	2
10	32.15.15.2010	RAWAGEMPOL WETAN	10	3215081010	RAWAGEMPOL WETAN	1
11	32.15.15.2004	MUARABARU	11	3215081011	MUARABARU	2
12	32.15.15.2003	MUARA	12	3215081012	MUARA	2

http://jabar.bps.go.id

Catatan :
*) 1. Perkotaan
2. Perdesaan

DAFTAR DESA/KELURAHAN

PROVINSI : [32] JAWA BARAT
KABUPATEN : [15] KARAWANG
KECAMATAN : [082] CILAMAYA KULON

Data Kemendagri			MFD 2021 Semester 2			
No	Kode	Nama Desa	No	Kode	Nama Desa	Status*
1	32.15.23.2006	KIARA	1	3215082001	KIARA	2
2	32.15.23.2005	BAYUR KIDUL	2	3215082002	BAYUR KIDUL	2
3	32.15.23.2004	BAYUR LOR	3	3215082003	BAYUR LOR	2
4	32.15.23.2003	LANGENSARI	4	3215082004	LANGENSARI	2
5	32.15.23.2001	SUKAMULYA	5	3215082005	SUKAMULYA	2
6	32.15.23.2010	PASIRUKEM	6	3215082006	PASIRUKEM	2
7	32.15.23.2012	SUKAJAYA	7	3215082007	SUKAJAYA	2
8	32.15.23.2011	PASIRJAYA	8	3215082008	PASIRJAYA	2
9	32.15.23.2009	MUKTIJAYA	9	3215082009	MUKTIJAYA	2
10	32.15.23.2002	TEGALURUNG	10	3215082010	TEGALURUNG	2
11	32.15.23.2007	MANGGUNG-JAYA	11	3215082011	MANGGUNG-JAYA	2
12	32.15.23.2008	SUMURGEDE	12	3215082012	SUMURGEDE	2

Catatan :
*) 1. Perkotaan
2. Perdesaan

https://jabar.bps.go.id

PROVINSI : [32] JAWA BARAT
KABUPATEN : [15] KARAWANG
KECAMATAN : [090] LEMAH ABANG

Data Kemendagri			MFD 2021 Semester 2			
No	Kode	Nama Desa	No	Kode	Nama Desa	Status*
1	32.15.19.2002	CIWARINGIN	1	3215090001	CIWARINGIN	2
2	32.15.19.2003	WARINGIN KARYA	2	3215090002	WARINGIN KARYA	2
3	32.15.19.2006	PASIRTANJUNG	3	3215090003	PASIRTANJUNG	2
4	32.15.19.2005	KARANG TANJUNG	4	3215090004	KARANG TANJUNG	2
5	32.15.19.2004	KEDAWUNG	5	3215090005	KEDAWUNG	1
6	32.15.19.2007	LEMAHABANG	6	3215090006	LEMAHABANG	1
7	32.15.19.2001	KARYAMUKTI	7	3215090007	KARYAMUKTI	1
8	32.15.19.2009	PULOJAYA	8	3215090008	PULOJAYA	1
9	32.15.19.2010	PULOKELAPA	9	3215090009	PULOKELAPA	2
10	32.15.19.2008	LEMAHMUKTI	10	3215090010	LEMAHMUKTI	2
11	32.15.19.2011	PULOMULYA	11	3215090011	PULOMULYA	21

Catatan :
*) 1. Perkotaan
2. Perdesaan

https://jabar.bps.go.id

DAFTAR DESA/KELURAHAN

PROVINSI : [32] JAWA BARAT
KABUPATEN : [15] KARAWANG
KECAMATAN : [100] TELAGASARI

Data Kemendagri			MFD 2021 Semester 2			
No	Kode	Nama Desa	No	Kode	Nama Desa	Status*
1	32.15.17.2003	PASIRTALAGA	1	3215100001	PASIRTALAGA	1
2	32.15.17.2001	TELAGAMULYA	2	3215100002	TALAGAMULYA	2
3	32.15.17.2004	CARIUMULYA	3	3215100003	CARIUMULYA	2
4	32.15.17.2011	CILEWO	4	3215100004	CILEWO	2
5	32.15.17.2013	LINGGARSARI	5	3215100005	LINGGARSARI	2
6	32.15.17.2014	PULOSARI	6	3215100006	PULOSARI	2
7	32.15.17.2012	CIWULAN	7	3215100007	CIWULAN	2
8	32.15.17.2008	KALIJAYA	8	3215100008	KALIJAYA	2
9	32.15.17.2010	CADAS KERTA-JAYA	9	3215100009	CADASKERTA-JAYA	2
10	32.15.17.2006	KALIBUAYA	10	3215100010	KALIBUAYA	1
11	32.15.17.2002	TELAGASARI	11	3215100011	TALAGASARI	1
12	32.15.17.2005	PASIRMUKTI	12	3215100012	PASIRMUKTI	2
13	32.15.17.2007	PASIRKA-MUNING	13	3215100013	PASIRKA-MUNING	2
14	32.15.17.2009	KALISARI	14	3215100014	KALISARI	2

Catatan :
*) 1. Perkotaan
2. Perdesaan

https://jabar.bps.go.id

PROVINSI : [32] JAWA BARAT
KABUPATEN : [15] KARAWANG
KECAMATAN : [111] MAJALAYA

Data Kemendagri			MFD 2021 Semester 2			
No	Kode	Nama Desa	No	Kode	Nama Desa	Status*
1	32.15.21.2003	PASIRJENGKOL	1	3215111001	PASIRJENGKOL	2
2	32.15.21.2001	MAJALAYA	2	3215111002	MAJALAYA	2
3	32.15.21.2002	CIRANGGON	3	3215111003	CIRANGGON	1
4	32.15.21.2005	SARIJAYA	4	3215111004	SARIJAYA	2
5	32.15.21.2008	BANGLE	5	3215111005	BANGLE	2
6	32.15.21.2007	LEMAHMULYA	6	3215111006	LEMAHMULYA	2
7	32.15.21.2006	PASIRMULYA	7	3215111007	PASIRMULYA	2

Catatan :
*) 1. Perkotaan
2. Perdesaan

https://jabar.bps.go.id

DAFTAR DESA/KELURAHAN

PROVINSI : [32] JAWA BARAT
KABUPATEN : [15] KARAWANG
KECAMATAN : [112] KARAWANG TIMUR

Data Kemendagri			MFD 2021 Semester 2			
No	Kode	Nama Kelurahan	No	Kode	Nama Kelurahan	Status*
1	32.15.26.1002	ADIARSA TIMUR	1	3215112001	ADIARSA TIMUR	1
2	32.15.26.2006	WARUNG BAMBU	2	3215112002	WARUNG BAMBU	1
3	32.15.26.2007	KONDANG-JAYA	3	3215112003	KONDANG-JAYA	1
4	32.15.26.2005	MARGASARI	4	3215112004	MARGASARI	1
5	32.15.26.1001	KARAWANG WETAN	5	3215112005	KARAWANG WETAN	1
6	32.15.26.1003	PALUMBON-SARI	6	3215112006	PALUMBON-SARI	1
7	32.15.26.1004	PLAWAD	7	3215112007	PLAWAD	2
8	32.15.26.2008	TEGAL SAWAH	8	3215112008	TEGALSAWAH	2

Catatan :
*) 1. Perkotaan
2. Perdesaan

https://jabar.bps.go.id

PROVINSI : [32] JAWA BARAT
KABUPATEN : [15] KARAWANG
KECAMATAN : [113] KARAWANG BARAT

Data Kemendagri			MFD 2021 Semester 2			
No	Kode	Nama Kelurahan	No	Kode	Nama Kelurahan	Status*
1	32.15.01.1003	ADIARSA BARAT	1	3215113001	ADIARSA BARAT	1
2	32.15.01.1011	NAGASARI	2	3215113002	NAGASARI	1
3	32.15.01.1001	KARAWANG KULON	3	3215113003	KARAWANG KULON	1
4	32.15.01.1005	TANJUNGPURA	4	3215113004	TANJUNGPURA	1
5	32.15.01.1006	TANJUNG MEKAR	5	3215113005	TANJUNG MEKAR	1
6	32.15.01.1010	KARAN G PAWITAN	6	3215113006	KARANG PAWITAN	1
7	32.15.01.1012	MEKARJATI	7	3215113007	MEKARJATI	2
8	32.15.01.1007	TUNGGAKJATI	8	3215113008	TUNGGAKJATI	1

https://jabar.bps.go.id

Catatan :
*) 1. Perkotaan
2. Perdesaan

DAFTAR DESA/KELURAHAN

PROVINSI : [32] JAWA BARAT
KABUPATEN : [15] KARAWANG
KECAMATAN : [120] RAWAMERTA

Data Kemendagri			MFD 2021 Semester 2			
No	Kode	Nama Desa	No	Kode	Nama Desa	Status*
1	32.15.18.2004	PASIRKALIKI	1	3215120001	PASIRKALIKI	2
2	32.15.18.2002	KUTAWARGI	2	3215120002	KUTAWARGI	2
3	32.15.18.2011	CIBADAK	3	3215120003	CIBADAK	2
4	32.15.18.2001	SUKAMERTA	4	3215120004	SUKAMERTA	1
5	32.15.18.2005	PASIRAWI	5	3215120005	PASIRAWI	2
6	32.15.18.2006	BALONGSARI	6	3215120006	BALONGSARI	1
7	32.15.18.2009	PURWAMEKAR	7	3215120007	PURWAMEKAR	2
8	32.15.18.2007	MEKARJAYA	8	3215120008	MEKARJAYA	2
9	32.15.18.2008	SEKARWANGI	9	3215120009	SEKARWANGI	2
10	32.15.18.2003	PANYINGKIRAN	10	3215120010	PANYINGKIRAN	2
11	32.15.18.2010	SUKAPURA	11	3215120011	SUKAPURA	1
12	32.15.18.2014	GOMBONG-SARI	12	3215120012	GOMBONG-SARI	2
13	32.15.18.2012	SUKARAJA	13	3215120013	SUKARAJA	2

Catatan :
*) 1. Perkotaan
2. Perdesaan

https://jabar.bps.go.id

PROVINSI : [32] JAWA BARAT
KABUPATEN : [15] KARAWANG
KECAMATAN : [130] TEMPURAN

Data Kemendagri			MFD 2021 Semester 2			
No	Kode	Nama Desa	No	Kode	Nama Desa	Status*
1	32.15.20.2002	DAYEUH LUHUR	1	3215130001	DAYEUH LUHUR	2
2	32.15.20.2004	LEMAHKARYA	2	3215130002	LEMAHKARYA	2
3	32.15.20.2003	LEMAHDUHUR	3	3215130003	LEMAHDUHUR	2
4	32.15.20.2005	LEMAHSUBUR	4	3215130004	LEMAHSUBUR	2
5	32.15.20.2006	LEMAHMAK-MUR	5	3215130005	LEMAHMAK-MUR	2
6	32.15.20.2012	PAGADUNGAN	6	3215130006	PAGADUNGAN	2
7	32.15.20.2008	PURWAJAYA	7	3215130007	PURWAJAYA	2
8	32.15.20.2016	JAYANEGARA	8	3215130008	JAYANEGARA	2
9	32.15.20.2013	TEMPURAN	9	3215130009	TEMPURAN	1
10	32.15.20.2017	CIPARAGEJAYA	10	3215130010	CIPARAGEJAYA	1
11	32.15.20.2014	CIKUNTUL	11	3215130011	CIKUNTUL	1
12	32.15.20.2011	SUMBERJAYA	12	3215130012	SUMBERJAYA	1
13	32.15.20.2001	PANCAKARYA	13	3215130013	PANCAKARYA	1
14	32.15.20.2010	TANJUNGJAYA	14	3215130014	TANJUNGJAYA	1

Catatan :
*) 1. Perkotaan
2. Perdesaan

https://jabar.bps.go.id

DAFTAR DESA/KELURAHAN

PROVINSI : [32] JAWA BARAT
KABUPATEN : [15] KARAWANG
KECAMATAN : [140] KUTAWALUYA

Data Kemendagri			MFD 2021 Semester 2			
No	Kode	Nama Desa	No	Kode	Nama Desa	Status*
1	32.15.07.2012	SINDANG-KARYA	1	3215140001	SINDANG-KARYA	2
2	32.15.07.2009	SINDANG-MUKTI	2	3215140002	SINDANG-MUKTI	2
3	32.15.07.2008	SINDANG MULYA	3	3215140003	SINDANG MULYA	2
4	32.15.07.2002	MULYAJAYA	4	3215140004	MULYAJAYA	2
5	32.15.07.2003	KUTAKARYA	5	3215140005	KUTAKARYA	1
6	32.15.07.2004	KUTAGANDOK	6	3215140006	KUTAGANDOK	1
7	32.15.07.2001	WALUYA	7	3215140007	WALUYA	2
8	32.15.07.2007	SAMPALAN	8	3215140008	SAMPALAN	1
9	32.15.07.2011	SINDANGSARI	9	3215140009	SINDANGSARI	2
10	32.15.07.2010	KUTARAJA	10	3215140010	KUTARAJA	2
11	32.15.07.2005	KUTAMUKTI	11	3215140011	KUTAMUKTI	1
12	32.15.07.2006	KUTAJAYA	12	3215140012	KUTAJAYA	1

Catatan :
*) 1. Perkotaan
2. Perdesaan

https://jabar.bps.go.id

PROVINSI : [32] JAWA BARAT
KABUPATEN : [15] KARAWANG
KECAMATAN : [150] RENGASDENGKLOK

Data Kemendagri			MFD 2021 Semester 2			
No	Kode	Nama Desa	No	Kode	Nama Desa	Status*
1	32.15.06.2008	KALANGSARI	1	3215150001	KALANGSARI	1
2	32.15.06.2009	KALANGSURIA	2	3215150002	KALANGSURIA	2
3	32.15.06.2006	KARYASARI	3	3215150003	KARYASARI	1
4	32.15.06.2007	DUKUHKARYA	4	3215150004	DUKUHKARYA	2
5	32.15.06.2005	AMANSARI	5	3215150005	AMANSARI	1
6	32.15.06.2001	RENGAS-DENGKLOK SELATAN	6	3215150006	RENGAS-DENGKLOK SELATAN	1
7	32.15.06.2002	RENGAS-DENGKLOK UTARA	7	3215150007	RENGAS-DENGKLOK UTARA	1
8	32.15.06.2003	KERTASARI	8	3215150008	KERTASARI	1
9	32.15.06.2004	DEWISARI	9	3215150009	DEWISARI	1

https://jabar.bps.go.id

Catatan :
*) 1. Perkotaan
2. Perdesaan

DAFTAR DESA/KELURAHAN

PROVINSI : [32] JAWA BARAT
KABUPATEN : [15] KARAWANG
KECAMATAN : [151] JAYAKERTA

Data Kemendagri			MFD 2021 Semester 2			
No	Kode	Nama Desa	No	Kode	Nama Desa	Status*
1	32.15.22.2002	KEMIRI	1	3215151001	KEMIRI	1
2	32.15.22.2003	MAKMURJAYA	2	3215151002	MAKMURJAYA	2
3	32.15.22.2001	JAYAMAKMUR	3	3215151003	JAYAMAKMUR	2
4	32.15.22.2005	JAYAKERTA	4	3215151004	JAYAKERTA	2
5	32.15.22.2004	KERTAJAYA	5	3215151005	KERTAJAYA	2
6	32.15.22.2007	CIPTAMARGA	6	3215151006	CIPTAMARGA	1
7	32.15.22.2006	MEDANGASEM	7	3215151007	MEDANGASEM	1
8	32.15.22.2008	KAMPUNG-SAWAH	8	3215151008	KAMPUNG-SAWAH	1

Catatan :
*) 1. Perkotaan
2. Perdesaan

https://jabar.bps.go.id

PROVINSI : [32] JAWA BARAT
KABUPATEN : [15] KARAWANG
KECAMATAN : [160] PEDES

Data Kemendagri			MFD 2021 Semester 2			
No	Kode	Nama Desa	No	Kode	Nama Desa	Status*
1	32.15.10.2012	JATIMULYA	1	3215160001	JATIMULYA	2
2	32.15.10.2003	KERTARA-HARJA	2	3215160006	KERTARA-HARJA	2
3	32.15.10.2002	KARANGJAYA	3	3215160007	KARANGJAYA	2
4	32.15.10.2018	MALANGSARI	4	3215160008	MALANGSARI	2
5	32.15.10.2007	KERTAMULYA	5	3215160009	KERTAMULYA	2
6	32.15.10.2001	PAYUNGSARI	6	3215160010	PAYUNGSARI	2
7	32.15.10.2016	RANGDU MULYA	7	3215160011	RANGDU MULYA	2
8	32.15.10.2010	LABANJAYA	8	3215160012	LABANJAYA	2
9	32.15.10.2005	SUNGAIBUNTU	9	3215160015	SUNGAIBUNTU	2
10	32.15.10.2017	KENDALJAYA	10	3215160016	KENDALJAYA	2
11	32.15.10.2006	DONGKAL	11	3215160017	DONGKAL	2
12	32.15.10.2008	PUSPASARI	12	3215160018	PUSPASARI	2

Catatan :
*) 1. Perkotaan
2. Perdesaan

https://jabar.bps.go.id

DAFTAR DESA/KELURAHAN

PROVINSI : [32] JAWA BARAT
KABUPATEN : [15] KARAWANG
KECAMATAN : [161] CILEBAR

Data Kemendagri			MFD 2021 Semester 2			
No	Kode	Nama Desa	No	Kode	Nama Desa	Status*
1	32.15.30.2007	SUKARATU	1	3215161001	SUKARATU	2
2	32.15.30.2008	CIPTAMARGI	2	3215161002	CIPTAMARGI	2
3	32.15.30.2010	TANJUNGSARI	3	3215161003	TANJUNGSARI	2
4	32.15.30.2009	MEKARPOHACI	4	3215161004	MEKARPOHACI	2
5	32.15.30.2001	KERTAMUKTI	5	3215161005	KERTAMUKTI	2
6	32.15.30.2004	CIKANDE	6	3215161006	CIKANDE	2
7	32.15.30.2002	RAWASARI	7	3215161007	RAWASARI	2
8	32.15.30.2005	KOSAMBIBATU	8	3215161008	KOSAMBIBATU	2
9	32.15.30.2003	PUSAKAJAYA SELATAN	9	3215161009	PUSAKAJAYA SELATAN	2
10	32.15.30.2006	PUSAKAJAYA UTARA	10	3215161010	PUSAKAJAYA UTARA	2

Catatan :
*) 1. Perkotaan
2. Perdesaan

https://jabar.bps.go.id

PROVINSI : [32] JAWA BARAT
KABUPATEN : [15] KARAWANG
KECAMATAN : [170] CIBUAYA

Data Kemendagri			MFD 2021 Semester 2			
No	Kode	Nama Desa	No	Kode	Nama Desa	Status*
1	32.15.11.2004	SUKASARI	1	3215170001	SUKASARI	2
2	32.15.11.2003	KERTARAHAYU	2	3215170002	KERTARAHAYU	2
3	32.15.11.2002	CIBUAYA	3	3215170003	CIBUAYA	2
4	32.15.11.2001	PAJATEN	4	3215170004	PAJATEN	1
5	32.15.11.2005	KEDUNGJERUK	5	3215170005	KEDUNGJERUK	2
6	32.15.11.2006	KALIDUNG-JAYA	6	3215170006	KALIDUNG-JAYA	2
7	32.15.11.2010	KEDUNGJAYA	7	3215170007	KEDUNGJAYA	2
8	32.15.11.2009	JAYAMULYA	8	3215170008	JAYAMULYA	2
9	32.15.11.2011	GEBANGJAYA	9	3215170009	GEBANGJAYA	2
10	32.15.11.2008	CEMARAJAYA	10	3215170010	CEMARAJAYA	1
11	32.15.11.2007	SEDARI	11	3215170011	SEDARI	2

https://jabar.bps.go.id

Catatan :
*) 1. Perkotaan
2. Perdesaan

DAFTAR DESA/KELURAHAN

PROVINSI : [32] JAWA BARAT
KABUPATEN : [15] KARAWANG
KECAMATAN : [180] TIRTAJAYA

Data Kemendagri			MFD 2021 Semester 2			
No	Kode	Nama Desa	No	Kode	Nama Desa	Status*
1	32.15.09.2004	MEDANKARYA	1	3215180001	MEDANKARYA	2
2	32.15.09.2002	PISANGSAMBO	2	3215180002	PISANGSAMBO	2
3	32.15.09.2001	SABAJAYA	3	3215180003	SABAJAYA	2
4	32.15.09.2003	GEMPOL-KARYA	4	3215180004	GEMPOL-KARYA	2
5	32.15.09.2008	SRIJAYA	5	3215180005	SRIJAYA	2
6	32.15.09.2009	KUTAMAKMUR	6	3215180006	KUTAMAKMUR	2
7	32.15.09.2010	BOLANG	7	3215180007	BOLANG	2
8	32.15.09.2011	SRIKAMULYAN	8	3215180008	SRIKAMULYAN	2
9	32.15.09.2007	SUMURLABAN	9	3215180009	SUMURLABAN	2
10	32.15.09.2005	TAMBAKSU-MUR	10	3215180010	TAMBAKSU-MUR	2
11	32.15.09.2006	TAMBAKSARI	11	3215180011	TAMBAKSARI	2

Catatan :
*) 1. Perkotaan
2. Perdesaan

https://jabar.bps.go.id

PROVINSI : [32] JAWA BARAT
KABUPATEN : [15] KARAWANG
KECAMATAN : [190] BATUJAYA

Data Kemendagri			MFD 2021 Semester 2			
No	Kode	Nama Desa	No	Kode	Nama Desa	Status*
1	32.15.08.2008	KUTAAMPEL	1	3215190001	KUTAAMPEL	1
2	32.15.08.2010	KARYAMAK-MUR	2	3215190002	KARYAMAK-MUR	1
3	32.15.08.2009	KARYAMULYA	3	3215190003	KARYAMULYA	1
4	32.15.08.2003	TELUKBANGO	4	3215190004	TELUKBANGO	2
5	32.15.08.2002	TELUKAMBULU	5	3215190005	TELUKAMBULU	2
6	32.15.08.2004	KARYABAKTI	6	3215190006	KARYABAKTI	2
7	32.15.08.2005	BATURADEN	7	3215190007	BATURADEN	2
8	32.15.08.2001	BATUJAYA	8	3215190008	BATUJAYA	1
9	32.15.08.2006	SERAGAN	9	3215190009	SERAGAN	2
10	32.15.08.2007	SEGARJAYA	10	3215190010	SEGARJAYA	2

https://jabar.bps.go.id

Catatan :
*) 1. Perkotaan
2. Perdesaan

DAFTAR DESA/KELURAHAN

PROVINSI : [32] JAWA BARAT
KABUPATEN : [15] KARAWANG
KECAMATAN : [200] PAKISJAYA

Data Kemendagri			MFD 2021 Semester 2			
No	Kode	Nama Desa	No	Kode	Nama Desa	Status*
1	32.15.12.2001	TELAGAJAYA	1	3215200001	TALAGAJAYA	2
2	32.15.12.2002	TELUKBUYUNG	2	3215200002	TELUKBUYUNG	2
3	32.15.12.2003	TANAHBARU	3	3215200003	TANAHBARU	2
4	32.15.12.2004	SOLOKAN	4	3215200004	SOLOKAN	2
5	32.15.12.2005	TANJUNG-BUNGIN	5	3215200005	TANJUNG-BUNGIN	2
6	32.15.12.2006	TANJUNG MEKAR	6	3215200006	TANJUNG MEKAR	2
7	32.15.12.2007	TANJUNGPAKIS	7	3215200007	TANJUNGPAKIS	2
8	32.15.12.2008	TELUKJAYA	8	3215200008	TELUKJAYA	2

Catatan :
*) 1. Perkotaan
2. Perdesaan

https://jabar.bps.go.id

KABUPATEN BEKASI

https://jatim.bps.go.id

https://jabar.bps.go.id

PROVINSI : [32] JAWA BARAT
KABUPATEN : [16] BEKASI

Data Kemendagri			MFD 2021 Semester 2		
No	Kode	Nama Kecamatan	No	Kode	Nama Kecamatan
1	32.16.18	SETU	1	3216010	SETU
2	32.16.21	SERANG BARU	2	3216021	SERANG BARU
3	32.16.20	CIKARANG PUSAT	3	3216022	CIKARANG PUSAT
4	32.16.19	CIKARANG SELATAN	4	3216023	CIKARANG SELATAN
5	32.16.22	CIBARUSAH	5	3216030	CIBARUSAH
6	32.16.23	BOJONGMANGU	6	3216031	BOJONGMANGU
7	32.16.11	CIKARANG TIMUR	7	3216041	CIKARANG TIMUR
8	32.16.12	KEDUNG WARINGIN	8	3216050	KEDUNGWARINGIN
9	32.16.09	CIKARANG UTARA	9	3216061	CIKARANG UTARA
10	32.16.10	KARANG BAHAGIA	10	3216062	KARANGBAHAGIA
11	32.16.07	CIBITUNG	11	3216070	CIBITUNG
12	32.16.08	CIKARANG BARAT	12	3216071	CIKARANG BARAT
13	32.16.06	TAMBUN SELATAN	13	3216081	TAMBUN SELATAN
14	32.16.05	TAMBUN UTARA	14	3216082	TAMBUN UTARA
15	32.16.02	BABELAN	15	3216090	BABELAN
16	32.16.01	TARUMAJAYA	16	3216100	TARUMAJAYA
17	32.16.04	TAMBELANG	17	3216110	TAMBELANG
18	32.16.03	SUKAWANGI	18	3216111	SUKAWANGI
19	32.16.15	SUKATANI	19	3216120	SUKATANI
20	32.16.14	SUKAKARYA	20	3216121	SUKAKARYA
21	32.16.13	PEBAYURAN	21	3216130	PEBAYURAN
22	32.16.16	CABANGBUNGIN	22	3216140	CABANGBUNGIN
23	32.16.17	MUARAGEMBONG	23	3216150	MUARA GEMBONG

https://jabar.bps.go.id

JUMLAH DESA/KELURAHAN PER KECAMATAN

PROVINSI : [32] JAWA BARAT
KABUPATEN : [16] BEKASI

Data Kemendagri				MFD 2021 Semester 2			
No	Kode	Nama Kecamatan	Jml Desa	No	Kode	Nama Kecamatan	Jml Desa
1	32.16.18	SETU	11	1	3216010	SETU	11
2	32.16.21	SERANG BARU	8	2	3216021	SERANG BARU	8
3	32.16.20	CIKARANG PUSAT	6	3	3216022	CIKARANG PUSAT	6
4	32.16.19	CIKARANG SELA-TAN	7	4	3216023	CIKARANG SELA-TAN	7
5	32.16.22	CIBARUSAH	7	5	3216030	CIBARUSAH	7
6	32.16.23	BOJONGMANGU	6	6	3216031	BOJONGMANGU	6
7	32.16.11	CIKARANG TIMUR	8	7	3216041	CIKARANG TIMUR	8
8	32.16.12	KEDUNG WAR-INGIN	7	8	3216050	KEDUNGWAR-INGIN	7
9	32.16.09	CIKARANG UTARA	11	9	3216061	CIKARANG UTARA	11
10	32.16.10	KARANG BAHA-GIA	8	10	3216062	KARANGBAHA-GIA	8
11	32.16.07	CIBITUNG	7	11	3216070	CIBITUNG	7
12	32.16.08	CIKARANG BARAT	11	12	3216071	CIKARANG BARAT	11
13	32.16.06	TAMBUN SELA-TAN	10	13	3216081	TAMBUN SELA-TAN	10
14	32.16.05	TAMBUN UTARA	8	14	3216082	TAMBUN UTARA	8
15	32.16.02	BABELAN	9	15	3216090	BABELAN	9
16	32.16.01	TARUMAJAYA	8	16	3216100	TARUMAJAYA	8
17	32.16.04	TAMBELANG	7	17	3216110	TAMBELANG	7
18	32.16.03	SUKAWANGI	7	18	3216111	SUKAWANGI	7
19	32.16.15	SUKATANI	7	19	3216120	SUKATANI	7
20	32.16.14	SUKAKARYA	7	20	3216121	SUKAKARYA	7
21	32.16.13	PEBAYURAN	13	21	3216130	PEBAYURAN	13
22	32.16.16	CABANGBUNGIN	8	22	3216140	CABANGBUNGIN	8
23	32.16.17	MUARAGEM-BONG	6	23	321650	MUARA GEM-BONG	6

https://jabar.bps.go.id

PROVINSI : [32] JAWA BARAT
KABUPATEN : [16] BEKASI
KECAMATAN : [010] SETU

Data Kemendagri			MFD 2021 Semester 2			
No	Kode	Nama Desa	No	Kode	Nama Desa	Status*
1	32.16.18.2009	RAGAMA-NUNGGAL	1	3216010001	RAGEMA-NUNGGAL	2
2	32.16.18.2010	MUKTIJAYA	2	3216010002	MUKTIJAYA	2
3	32.16.18.2011	KERTARAHAYU	3	3216010003	KERTARAHAYU	2
4	32.16.18.2008	CIKARAGEMAN	4	3216010004	CIKARAGEMAN	1
5	32.16.18.2006	TAMAN SARI	5	3216010005	TAMAN SARI	2
6	32.16.18.2007	TAMAN RA-HAYU	6	3216010006	TAMAN RA-HAYU	1
7	32.16.18.2003	BURANGKENG	7	3216010007	BURANGKENG	1
8	32.16.18.2004	CILEDUG	8	3216010008	CILEDUK	1
9	32.16.18.2005	CIBENING	9	3216010009	CIBENING	1
10	32.16.18.2001	CIJENGKOL	10	3216010012	CIJENGKOL	1
11	32.16.18.2002	LUBANGBUAYA	11	3216010013	LUBANGBUAYA	1

Catatan :
*) 1. Perkotaan
2. Perdesaan

https://jabar.bps.go.id

DAFTAR DESA/KELURAHAN

PROVINSI : [32] JAWA BARAT
KABUPATEN : [16] BEKASI
KECAMATAN : [021] SERANG BARU

Data Kemendagri			MFD 2021 Semester 2			
No	Kode	Nama Desa	No	Kode	Nama Desa	Status*
1	32.16.21.2004	JAYAMULYA	1	3216021001	JAYAMULYA	2
2	32.16.21.2001	SUKARAGAM	2	3216021002	SUKARAGAM	1
3	32.16.21.2002	SIRNAJAYA	3	3216021003	SIRNAJAYA	1
4	32.16.21.2005	NAGACIPTA	4	3216021004	NAGACIPTA	2
5	32.16.21.2006	NAGASARI	5	3216021005	NAGASARI	2
6	32.16.21.2007	CILANGKARA	6	3216021006	CILANGKARA	1
7	32.16.21.2003	SUKASARI	7	3216021007	SUKASARI	1
8	32.16.21.2008	JAYASAMPUR-NA	8	3216021008	JAYASAMPUR-NA	2

Catatan :
*) 1. Perkotaan
2. Perdesaan

https://jabar.bps.go.id

PROVINSI : [32] JAWA BARAT
KABUPATEN : [16] BEKASI
KECAMATAN : [022] CIKARANG PUSAT

Data Kemendagri			MFD 2021 Semester 2			
No	Kode	Nama Desa	No	Kode	Nama Desa	Status*
1	32.16.20.2001	CICAU	1	3216022001	CICAU	1
2	32.16.20.2002	SUKAMAHI	2	3216022002	SUKAMAHI	1
3	32.16.20.2003	PASIRRANJI	3	3216022003	PASIRRANJI	2
4	32.16.20.2006	PASIRTANJUNG	4	3216022004	PASIRTANJUNG	1
5	32.16.20.2004	HEGARMUKTI	5	3216022005	HEGARMUKTI	1
6	32.16.20.2005	JAYAMUKTI	6	3216022006	JAYAMUKTI	1

Catatan :
*) 1. Perkotaan
2. Perdesaan

https://jabar.bps.go.id

DAFTAR DESA/KELURAHAN

PROVINSI : [32] JAWA BARAT
KABUPATEN : [16] BEKASI
KECAMATAN : [023] CIKARANG SELATAN

Data Kemendagri			MFD 2021 Semester 2			
No	Kode	Nama Desa	No	Kode	Nama Desa	Status*
1	32.16.19.2002	SUKASEJATI	1	3216023001	SUKASEJATI	2
2	32.16.19.2003	CIANTRA	2	3216023002	CIANTRA	1
3	32.16.19.2004	SUKADAMI	3	3216023003	SUKADAMI	1
4	32.16.19.2006	SERANG	4	3216023004	SERANG	1
5	32.16.19.2005	SUKARESMI	5	3216023005	SUKARESMI	1
6	32.16.19.2001	CIBATU	6	3216023006	CIBATU	1
7	32.16.19.2007	PASIRSARI	7	3216023007	PASIRSARI	1

Catatan :
*) 1. Perkotaan
2. Perdesaan

https://jabar.bps.go.id

PROVINSI : [32] JAWA BARAT
KABUPATEN : [16] BEKASI
KECAMATAN : [030] CIBARUSAH

Data Kemendagri			MFD 2021 Semester 2			
No	Kode	Nama Desa	No	Kode	Nama Desa	Status*
1	32.16.22.2006	CIBARUSAH JAYA	1	3216030001	CIBARUSAH-JAYA	1
2	32.16.22.2005	CIBARUSAH KOTA	2	3216030002	CIBARUSAH KOTA	1
3	32.16.22.2007	SINDANG MULYA	3	3216030003	SINDANG MULYA	1
4	32.16.22.2004	WIBAWA MULYA	4	3216030004	WIBAWA MULYA	2
5	32.16.22.2001	SIRNAJAYA	5	3216030005	SIRNAJAYA	1
6	32.16.22.2002	RIDOGALIH	6	3216030006	RIDOGALIH	1
7	32.16.22.2003	RIDOMANAH	7	3216030007	RIDOMANAH	1

Catatan :
*) 1. Perkotaan
2. Perdesaan

https://jabar.bps.go.id

DAFTAR DESA/KELURAHAN

PROVINSI : [32] JAWA BARAT
KABUPATEN : [16] BEKASI
KECAMATAN : [031] BOJONGMANGU

Data Kemendagri			MFD 2021 Semester 2			
No	Kode	Nama Desa	No	Kode	Nama Desa	Status*
1	32.16.23.2002	KARANG-INDAH	1	3216031001	KARANG-INDAH	2
2	32.16.23.2001	KARANG MULYA	2	3216031002	KARANG MULYA	2
3	32.16.23.2003	BOJONG MANGU	3	3216031003	BOJONG MANGU	2
4	32.16.23.2006	MEDALKRISNA	4	3216031004	MEDALKRISNA	2
5	32.16.23.2005	SUKAMUKTI	5	3216031005	SUKAMUKTI	2
6	32.16.23.2004	SUKABUNGAH	6	3216031006	SUKABUNGAH	2

Catatan :
*) 1. Perkotaan
2. Perdesaan

https://jabar.bps.go.id

PROVINSI : [32] JAWA BARAT
KABUPATEN : [16] BEKASI
KECAMATAN : [041] CIKARANG TIMUR

Data Kemendagri			MFD 2021 Semester 2			
No	Kode	Nama Desa	No	Kode	Nama Desa	Status*
1	32.16.11.1007	SERTAJAYA	1	3216041001	SERTAJAYA	1
2	32.16.11.2003	HEGARMANAH	2	3216041002	HEGARMANAH	2
3	32.16.11.2002	CIPAYUNG	3	3216041003	CIPAYUNG	1
4	32.16.11.2004	JATIREJA	4	3216041004	JATIREJA	1
5	32.16.11.2005	JATIBARU	5	3216041005	JATIBARU	1
6	32.16.11.2001	TANJUNGBARU	6	3216041006	TANJUNGBARU	1
7	32.16.11.2006	LABANSARI	7	3216041007	LABANSARI	2
8	32.16.11.2008	KARANGSARI	8	3216041008	KARANGSARI	1

Catatan :
*) 1. Perkotaan
2. Perdesaan

https://jabar.bps.go.id

DAFTAR DESA/KELURAHAN

PROVINSI : [32] JAWA BARAT
KABUPATEN : [16] BEKASI
KECAMATAN : [050] KEDUNG WARINGIN

Data Kemendagri			MFD 2021 Semester 2			
No	Kode	Nama Desa	No	Kode	Nama Desa	Status*
1	32.16.12.2006	BOJONGSARI	1	3216050002	BOJONGSARI	1
2	32.16.12.2007	KEDUNG WARINGIN	2	3216050003	KEDUNG WARINGIN	1
3	32.16.12.2002	WARINGINJAYA	3	3216050004	WARINGINJAYA	1
4	32.16.22.2001	KARANGSAM-BUNG	4	3216050005	KARANGSAM-BUNG	1
5	32.16.12.2005	KARANGHA-RUM	5	3216050007	KARANGHA-RUM	2
6	32.16.12.2004	MEKARJAYA	6	3216050008	MEKARJAYA	2
7	32.16.12.2003	KARANGME-KAR	7	3216050009	KARANGME-KAR	2

Catatan :
*) 1. Perkotaan
2. Perdesaan

https://jabar.bps.go.id

PROVINSI : [32] JAWA BARAT
KABUPATEN : [16] BEKASI
KECAMATAN : [061] CIKARANG UTARA

Data Kemendagri			MFD 2021 Semester 2			
No	Kode	Nama Desa	No	Kode	Nama Desa	Status*
1	32.16.09.2011	WANGUNHAR-JA	1	3216061001	WANGUNHAR-JA	1
2	32.16.09.2009	HARJAMEKAR	2	3216061002	HARJAMEKAR	1
3	32.16.09.2006	PASIRGOM-BONG	3	3216061003	PASIRGOM-BONG	1
4	32.16.09.2010	MEKARMUKTI	4	3216061004	MEKARMUKTI	1
5	32.16.09.2007	SIMPANGAN	5	3216061005	SIMPANGAN	1
6	32.16.09.2008	TANJUNGSARI	6	3216061006	TANJUNGSARI	1
7	32.16.09.2001	CIKARANG KOTA	7	3216061007	CIKARANG KOTA	1
8	32.16.09.2002	KARANGBARU	8	3216061008	KARANGBARU	1
9	32.16.09.2003	KARANGASIH	9	3216061009	KARANGASIH	1
10	32.16.09.2005	KARANG RAHARJA	10	3216061010	KARANG RAHARJA	1
11	32.16.09.2004	WALUYA	11	3216061011	WALUYA	1

Catatan :
*) 1. Perkotaan
2. Perdesaan

https://jabar.bps.go.id

DAFTAR DESA/KELURAHAN

PROVINSI : [32] JAWA BARAT
KABUPATEN : [16] BEKASI
KECAMATAN : [062] KARANGBAHAGIA

Data Kemendagri			MFD 2021 Semester 2			
No	Kode	Nama Desa	No	Kode	Nama Desa	Status*
1	32.16.10.2001	SUKARAYA	1	3216062001	SUKARAYA	1
2	32.16.10.2002	KARANG RAHAYU	2	3216062002	KARANG RAHAYU	1
3	32.16.10.2003	KARANGSETIA	3	3216062003	KARANGSETIA	2
4	32.16.10.2007	KARANGSATU	4	3216062004	KARANGSATU	2
5	32.16.10.2008	KARANGMUKTI	5	3216062005	KARANGMUKTI	2
6	32.16.10.2004	KARANG ANYAR	6	3216062006	KARANG ANYAR	2
7	32.16.10.2005	KARANGBA-HAGIA	7	3216062007	KARANGBA-HAGIA	2
8	32.16.10.2006	KARANGSEN-TOSA	8	3216062008	KARANGSEN-TOSA	1

Catatan :
*) 1. Perkotaan
2. Perdesaan

https://jabar.bps.go.id

PROVINSI : [32] JAWA BARAT
KABUPATEN : [16] BEKASI
KECAMATAN : [070] CIBITUNG

Data Kemendagri			MFD 2021 Semester 2			
No	Kode	Nama Desa	No	Kode	Nama Desa	Status*
1	32.16.07.2007	CIBUNTU	1	3216070006	CIBUNTU	1
2	32.16.07.1001	WANASARI	2	3216070013	WANASARI	1
3	32.16.07.2002	WANAJAYA	3	3216070014	WANAJAYA	1
4	32.16.07.2006	SUKAJAYA	4	3216070015	SUKAJAYA	1
5	32.16.07.2003	KERTAMUKTI	5	3216070016	KERTAMUKTI	1
6	32.16.07.2004	MUKTIWARI	6	3216070017	MUKTIWARI	2
7	32.16.07.2005	SARIMUKTI	7	3216070018	SARIMUKTI	2

Catatan :
*) 1. Perkotaan
2. Perdesaan

https://jabar.bps.go.id

DAFTAR DESA/KELURAHAN

PROVINSI : [32] JAWA BARAT
KABUPATEN : [16] BEKASI
KECAMATAN : [071] CIKARANG BARAT

Data Kemendagri			MFD 2021 Semester 2			
No	Kode	Nama Desa	No	Kode	Nama Desa	Status*
1	32.16.08.2001	TELAJUNG	1	3216071001	TELAJUNG	1
2	32.16.08.2002	CIKEDOKAN	2	3216071002	CIKEDOKAN	1
3	32.16.08.2003	JATIWANGI	3	3216071003	JATIWANGI	1
4	32.16.08.2004	MEKARWANGI	4	3216071004	MEKARWANGI	1
5	32.16.08.2005	GANDAMEKAR	5	3216071005	GANDAMEKAR	1
6	32.16.08.2006	DANAUINDAH	6	3216071006	DANAUINDAH	1
7	32.16.08.2007	GANDASARI	7	3216071007	GANDASARI	1
8	32.16.08.2008	SUKADANAU	8	3216071008	SUKADANAU	1
9	32.16.08.2009	TELAGA ASIH	9	3216071009	TELAGA ASIH	1
10	32.16.08.2010	TELAGAMURNI	10	3216071010	TELAGAMURNI	1
11	32.16.08.2011	KALIJAYA	11	3216071011	KALIJAYA	1

Catatan :
*) 1. Perkotaan
2. Perdesaan

https://jabar.bps.go.id

PROVINSI : [32] JAWA BARAT
KABUPATEN : [16] BEKASI
KECAMATAN : [081] TAMBUN SELATAN

Data Kemendagri			MFD 2021 Semester 2			
No	Kode	Nama Desa	No	Kode	Nama Desa	Status*
1	32.16.06.1001	JATIMULYA	1	3216081001	JATIMULYA	1
2	32.16.06.2002	LAMBANGSARI	2	3216081002	LAMBANGSARI	1
3	32.16.06.2003	LAMBANGJAYA	3	3216081003	LAMBANGJAYA	1
4	32.16.06.2004	TAMBUN	4	3216081004	TAMBUN	1
5	32.16.06.2005	SETIADARMA	5	3216081005	SETIADARMA	1
6	32.16.06.2006	SETIAMEKAR	6	3216081006	SETIAMEKAR	1
7	32.16.06.2007	MEKARSARI	7	3216081007	MEKARSARI	1
8	32.16.06.2008	TRIDAYASAKTI	8	3216081008	TRIDAYASAKTI	1
9	32.16.06.2009	MANGUNJAYA	9	3216081009	MANGUNJAYA	1
10	32.16.06.2010	SUMBERJAYA	10	3216081010	SUMBERJAYA	1

Catatan :
*) 1. Perkotaan
2. Perdesaan

https://jabar.bps.go.id

DAFTAR DESA/KELURAHAN

PROVINSI : [32] JAWA BARAT
KABUPATEN : [16] BEKASI
KECAMATAN : [082] TAMBUN UTARA

Data Kemendagri			MFD 2021 Semester 2			
No	Kode	Nama Desa	No	Kode	Nama Desa	Status*
1	32.16.05.2008	KARANG SATRIA	1	3216082001	KARANG SATRIA	1
2	32.16.05.2001	SATRIAJAYA	2	3216082002	SATRIAJAYA	1
3	32.16.05.2002	JEJALENJAYA	3	3216082003	JEJALENJAYA	1
4	32.16.05.2003	SATRIAMEKAR	4	3216082004	SATRIAMEKAR	1
5	32.16.05.2004	SRIAMUR	5	3216082005	SRIAMUR	1
6	32.16.05.2005	SRIMUKTI	6	3216082006	SRIMUKTI	2
7	32.16.05.2006	SRIJAYA	7	3216082007	SRIJAYA	2
8	32.16.05.2007	SRIMAHI	8	3216082008	SRIMAHI	2

Catatan :
*) 1. Perkotaan
2. Perdesaan

https://jabar.bps.go.id

PROVINSI : [32] JAWA BARAT
KABUPATEN : [16] BEKASI
KECAMATAN : [090] BABELAN

Data Kemendagri			MFD 2021 Semester 2			
No	Kode	Nama Desa	No	Kode	Nama Desa	Status*
1	32.16.02.1006	BAHAGIA	1	3216090001	BAHAGIA	1
2	32.16.02.1007	KEBALEN	2	3216090002	KEBALEN	1
3	32.16.02.2008	BABELAN KOTA	3	3216090003	BABELAN KOTA	1
4	32.16.02.2003	KEDUNG PENGAWAS	4	3216090004	KEDUNG PENGAWAS	1
5	32.16.02.2009	KEDUNGJAYA	5	3216090005	KEDUNGJAYA	2
6	32.16.02.2001	BUNIBAKTI	6	3216090006	BUNIBAKTI	2
7	32.16.02.2002	MUARABAKTI	7	3216090007	MUARABAKTI	2
8	32.16.02.2005	PANTAI HURIP	8	3216090008	PANTAI HURIP	2
9	32.16.02.2004	HURIP JAYA	9	3216090009	HURIP JAYA	2

https://jabar.bps.go.id

Catatan :
*) 1. Perkotaan
2. Perdesaan

DAFTAR DESA/KELURAHAN

PROVINSI : [32] JAWA BARAT
KABUPATEN : [16] BEKASI
KECAMATAN : [100] TARUMAJAYA

Data Kemendagri			MFD 2021 Semester 2			
No	Kode	Nama Desa	No	Kode	Nama Desa	Status*
1	32.16.01.2001	PUSAKA RAKYAT	1	3216100001	PUSAKA RAKYAT	1
2	32.16.01.2002	SETIA ASIH	2	3216100002	SETIA ASIH	1
3	32.16.01.2003	PAHLAWAN SETIA	3	3216100003	PAHLAWAN SETIA	2
4	32.16.01.2004	SETIAMULYA	4	3216100004	SETIAMULYA	2
5	32.16.01.2005	SAGARA MAK-MUR	5	3216100005	SEGARAMAK-MUR	1
6	32.16.01.2006	PANTAI MAK-MUR	6	3216100006	PANTAIMAK-MUR	1
7	32.16.01.2007	SEGARAJAYA	7	3216100007	SEGARAJAYA	1
8	32.16.01.2008	SAMUDRA JAYA	8	3216100008	SAMUDRAJAYA	2

Catatan :
*) 1. Perkotaan
2. Perdesaan

https://jabar.bps.go.id

PROVINSI : [32] JAWA BARAT
KABUPATEN : [16] BEKASI
KECAMATAN : [110] TAMBELANG

Data Kemendagri			MFD 2021 Semester 2			
No	Kode	Nama Desa	No	Kode	Nama Desa	Status*
1	32.16.04.2002	SUKAMAJU	1	3216110003	SUKAMAJU	2
2	32.16.04.2003	SUKARAJA	2	3216110004	SUKARAJA	2
3	32.16.04.2004	SUKARAPIH	3	3216110005	SUKARAPIH	2
4	32.16.04.2005	SUKARAHAYU	4	3216110006	SUKARAHAYU	2
5	32.16.04.2007	SUKABAKTI	5	3216110007	SUKABAKTI	2
6	32.16.04.2001	SUKAWIJAYA	6	3216110008	SUKAWIJAYA	2
7	32.16.04.2006	SUKAMANTRI	7	3216110009	SUKAMANTRI	2

Catatan :
*) 1. Perkotaan
2. Perdesaan

https://jabar.bps.go.id

DAFTAR DESA/KELURAHAN

PROVINSI : [32] JAWA BARAT
KABUPATEN : [16] BEKASI
KECAMATAN : [111] SUKAWANGI

Data Kemendagri			MFD 2021 Semester 2			
No	Kode	Nama Desa	No	Kode	Nama Desa	Status*
1	32.16.03.2007	SUKAMEKAR	1	3216111001	SUKAMEKAR	2
2	32.16.03.2003	SUKADAYA	2	3216111002	SUKADAYA	2
3	32.16.03.2002	SUKABUDI	3	3216111003	SUKABUDI	1
4	32.16.03.2004	SUKAWANGI	4	3216111004	SUKAWANGI	2
5	32.16.03.2005	SUKAKERTA	5	3216111005	SUKAKERTA	2
6	32.16.03.2001	SUKARINGIN	6	3216111006	SUKARINGIN	2
7	32.16.03.2006	SUKATENANG	7	3216111007	SUKATENANG	2

Catatan :
*) 1. Perkotaan
2. Perdesaan

https://jabar.bps.go.id

PROVINSI : [32] JAWA BARAT
KABUPATEN : [16] BEKASI
KECAMATAN : [120] SUKATANI

Data Kemendagri			MFD 2021 Semester 2			
No	Kode	Nama Desa	No	Kode	Nama Desa	Status*
1	32.16.15.2004	SUKASASIH	1	3216120001	SUKASASIH	2
2	32.16.15.2005	SUKARUKUN	2	3216120002	SUKARUKUN	1
3	32.16.15.2006	BANJARSARI	3	3216120003	BANJARSARI	2
4	32.16.15.2003	SUKAHURIP	4	3216120004	SUKAHURIP	2
5	32.16.15.2002	SUKAMANAH	5	3216120005	SUKAMANAH	1
6	32.16.15.2001	SUKAMULYA	6	3216120006	SUKAMULYA	1
7	32.16.15.2007	SUKADARMA	7	3216120007	SUKADARMA	1

Catatan :
*) 1. Perkotaan
2. Perdesaan

https://jabar.bps.go.id

DAFTAR DESA/KELURAHAN

PROVINSI : [32] JAWA BARAT
KABUPATEN : [16] BEKASI
KECAMATAN : [121] SUKAKARYA

Data Kemendagri			MFD 2021 Semester 2			
No	Kode	Nama Desa	No	Kode	Nama Desa	Status*
1	32.16.14.2005	SUKAJADI	1	3216121001	SUKAJADI	1
2	32.16.14.2007	SUKAMAKMUR	2	3216121002	SUKAMAKMUR	2
3	32.16.14.2004	SUKALAKSANA	3	3216121003	SUKALAKSANA	2
4	32.16.14.2006	SUKAKARSA	4	3216121004	SUKAKARSA	2
5	32.16.14.2003	SUKAKARYA	5	3216121005	SUKAKARYA	2
6	32.16.14.2002	SUKAINDAH	6	3216121006	SUKAINDAH	2
7	32.16.14.2001	SUKAMURNI	7	3216121007	SUKAMURNI	2

Catatan :
*) 1. Perkotaan
2. Perdesaan

https://jabar.bps.go.id

PROVINSI : [32] JAWA BARAT
KABUPATEN : [16] BEKASI
KECAMATAN : [130] PEBAYURAN

Data Kemendagri			MFD 2021 Semester 2			
No	Kode	Nama Desa	No	Kode	Nama Desa	Status*
1	32.16.13.2012	BANTARSARI	1	3216130001	BANTARSARI	2
2	32.16.13.2013	BANTARJAYA	2	3216130002	BANTARJAYA	1
3	32.16.13.1011	KERTASARI	3	3216130003	KERTASARI	1
4	32.16.13.2010	KERTAJAYA	4	3216130004	KERTAJAYA	2
5	32.16.13.2009	KARANGHAUR	5	3216130005	KARANGHAUR	2
6	32.16.13.2008	KARANGPARTI	6	3216130006	KARANGPARTI	2
7	32.16.13.2005	KARANGREJA	7	3216130007	KARANGREJA	2
8	32.16.13.2006	KARANGJAYA	8	3216130008	KARANGJAYA	2
9	32.16.13.2007	SUMBERSARI	9	3216130009	SUMBERSARI	2
10	32.16.13.2004	SUMBERREJA	10	3216130010	SUMBERREJA	2
11	32.16.13.2003	SUMBERHURIP	11	3216130011	SUMBERHURIP	2
12	32.16.13.2002	KARANGSE-GAR	12	3216130012	KARANGSE-GAR	2
13	32.16.13.2001	KARANGHAR-JA	13	3216130013	KARANGHAR-JA	2

Catatan :
*) 1. Perkotaan
2. Perdesaan

https://jabar.bps.go.id

DAFTAR DESA/KELURAHAN

PROVINSI : [32] JAWA BARAT
KABUPATEN : [16] BEKASI
KECAMATAN : [140] CABANGBUNGIN

Data Kemendagri			MFD 2021 Semester 2			
No	Kode	Nama Desa	No	Kode	Nama Desa	Status*
1	32.16.16.2001	JAYABAKTI	1	3216140001	JAYABAKTI	2
2	32.16.16.2004	SINDANGJAYA	2	3216140002	SINDANGJAYA	2
3	32.16.16.2003	SINDANGSARI	3	3216140003	SINDANGSARI	2
4	32.16.16.2002	JAYALAKSANA	4	3216140004	JAYALAKSANA	1
5	32.16.16.2005	SETIALAKSANA	5	3216140005	SETIALAKSANA	1
6	32.16.16.2007	LENGGAHJAYA	6	3216140006	LENGGAHJAYA	2
7	32.16.16.2006	SETIAJAYA	7	3216140007	SETIAJAYA	2
8	32.16.16.2008	LENGGAHSARI	8	3216140008	LENGGAHSARI	2

Catatan :
*) 1. Perkotaan
2. Perdesaan

https://jabar.bps.go.id

PROVINSI : [32] JAWA BARAT
KABUPATEN : [16] BEKASI
KECAMATAN : [150] MUARAGEMBONG

Data Kemendagri			MFD 2021 Semester 2			
No	Kode	Nama Desa	No	Kode	Nama Desa	Status*
1	32.16.17.2004	PANTAI HARA-PANJAYA	1	3216150001	PANTAI HARA-PANJAYA	2
2	32.16.17.2001	PANTAIMEKAR	2	3216150002	PANTAIMEKAR	1
3	32.16.17.2005	PANTAI SEDER-HANA	3	3216150003	PANTAI SEDER-HANA	2
4	32.16.17.2003	PANTAIBAKTI	4	3216150004	PANTAIBAKTI	2
5	32.16.17.2002	PANTAI BAHAGIA	5	3216150005	PANTAI BAHAGIA	2
6	32.16.17.2006	JAYASAKTI	6	3216150006	JAYASAKTI	2

Catatan :
*) 1. Perkotaan
2. Perdesaan

https://jabar.bps.go.id

https://jabar.bps.go.id

KABUPATEN BANDUNG BARAT

https://jabar.bps.go.id

https://jabar.bps.go.id

PROVINSI : [32] JAWA BARAT
KABUPATEN : [17] BANDUNG BARAT

Data Kemendagri			MFD 2021 Semester 2		
No	Kode	Nama Kecamatan	No	Kode	Nama Kecamatan
1	32.17.13	RONGGA	1	3217010	RONGGA
2	32.17.15	GUNUNGHALU	2	3217020	GUNUNGHALU
3	32.17.14	SINDANGKERTA	3	3217030	SINDANGKERTA
4	32.17.11	CILILIN	4	3217040	CILILIN
5	32.17.10	CIHAMPELAS	5	3217050	CIHAMPELAS
6	32.17.12	CIPONGKOR	6	3217060	CIPONGKOR
7	32.17.09	BATUJAJAR	7	3217070	BATUJAJAR
8	32.17.16	SAGULING	8	3217071	SAGULING
9	32.17.07	CIPATAT	9	3217080	CIPATAT
10	32.17.08	PADALARANG	10	3217090	PADALARANG
11	32.17.06	NGAMPRAH	11	3217100	NGAMPRAH
12	32.17.02	PARONGPONG	12	3217110	PARONGPONG
13	32.17.01	LEMBANG	13	3217120	LEMBANG
14	32.17.03	CISARUA	14	3217130	CISARUA
15	32.17.04	CIKALONGWETAN	15	3217140	CIKALONGWETAN
16	32.17.05	CIPEUNDEUY	16	3217150	CIPEUNDEUY

https://jabar.bps.go.id

JUMLAH DESA/KELURAHAN PER KECAMATAN

PROVINSI : [32] JAWA BARAT
KABUPATEN : [17] BANDUNG BARAT

Data Kemendagri				MFD 2021 Semester 2			
No	Kode	Nama Kecamatan	Jml Desa	No	Kode	Nama Kecamatan	Jml Desa
1	32.17.13	RONGGA	8	1	3217010	RONGGA	8
2	32.17.15	GUNUNGHALU	9	2	3217020	GUNUNGHALU	9
3	32.17.14	SINDANGKERTA	11	3	3217030	SINDANGKERTA	11
4	32.17.11	CILILIN	11	4	3217040	CILILIN	11
5	32.17.10	CIHAMPELAS	10	5	3217050	CIHAMPELAS	10
6	32.17.12	CIPONGKOR	14	6	3217060	CIPONGKOR	14
7	32.17.09	BATUJAJAR	7	7	3217070	BATUJAJAR	7
8	32.17.16	SAGULING	6	8	3217071	SAGULING	6
9	32.17.07	CIPATAT	12	9	3217080	CIPATAT	12
10	32.17.08	PADALARANG	10	10	3217090	PADALARANG	10
11	32.17.06	NGAMPRAH	11	11	3217100	NGAMPRAH	11
12	32.17.02	PARONGPONG	7	12	3217110	PARONGPONG	7
13	32.17.01	LEMBANG	16	13	3217120	LEMBANG	16
14	32.17.03	CISARUA	8	14	3217130	CISARUA	8
15	32.17.04	CIKALONG WETAN	13	15	3217140	CIKALONG WETAN	13
16	32.17.05	CIPEUNDEUY	12	16	3217150	CIPEUNDEUY	12

https://jabar.bps.go.id

PROVINSI : [32] JAWA BARAT
KABUPATEN : [17] BANDUNG BARAT
KECAMATAN : [010] RONGGA

Data Kemendagri			MFD 2021 Semester 2			
No	Kode	Nama Desa	No	Kode	Nama Desa	Status*
1	32.17.13.2005	CIDADAS	1	3217010001	CIDADAS	2
2	32.17.13.2001	CIBEDUG	2	3217010002	CIBEDUG	2
3	32.17.13.2007	SUKAMANAH	3	3217010003	SUKAMANAH	2
4	32.17.13.2002	BOJONG	4	3217010004	BOJONG	2
5	32.17.13.2003	BOJONG-SALAM	5	3217010005	BOJONG-SALAM	2
6	32.17.13.2006	CINENGAH	6	3217010006	CINENGAH	2
7	32.17.13.2008	SUKARESMI	7	3217010007	SUKARESMI	2
8	32.17.13.2004	CIBITUNG	8	3217010008	CIBITUNG	2

Catatan :
*) 1. Perkotaan
2. Perdesaan

https://jabar.bps.go.id

DAFTAR DESA/KELURAHAN

PROVINSI : [32] JAWA BARAT
KABUPATEN : [17] BANDUNG BARAT
KECAMATAN : [020] GUNUNGHALU

Data Kemendagri			MFD 2021 Semester 2			
No	Kode	Nama Desa	No	Kode	Nama Desa	Status*
1	32.17.15.2005	CILANGARI	1	3217020001	CILANGARI	2
2	32.17.15.2006	SINDANGJAYA	2	3217020002	SINDANGJAYA	2
3	32.17.15.2003	BUNIJAYA	3	3217020003	BUNIJAYA	2
4	32.17.15.2001	SIRNAJAYA	4	3217020004	SIRNAJAYA	2
5	32.17.15.2002	GUNUNGHALU	5	3217020005	GUNUNGHALU	1
6	32.17.15.2004	CELAK	6	3217020006	CELAK	2
7	32.17.15.2009	WARGA SALUYU	7	3217020007	WARGA SALUYU	2
8	32.17.15.2007	SUKASARI	8	3217020008	SUKASARI	2
9	32.17.15.2008	TAMANJAYA	9	3217020009	TAMANJAYA	2

Catatan :
*) 1. Perkotaan
2. Perdesaan

https://jabar.bps.go.id

PROVINSI : [32] JAWA BARAT
KABUPATEN : [17] BANDUNG BARAT
KECAMATAN : [030] SINDANGKERTA

Data Kemendagri			MFD 2021 Semester 2			
No	Kode	Nama Desa	No	Kode	Nama Desa	Status*
1	32.17.14.2006	MEKARWANGI	1	3217030001	MEKARWANGI	2
2	32.17.14.2010	WENINGGALIH	2	3217030002	WENINGGALIH	2
3	32.17.14.2011	WANGUNSARI	3	3217030003	WANGUNSARI	2
4	32.17.14.2003	BUNINAGARA	4	3217030004	BUNINAGARA	2
5	32.17.14.2004	CIKADU	5	3217030005	CIKADU	2
6	32.17.14.2009	RANCASENG-GANG	6	3217030006	RANCA SENG-GANG	2
7	32.17.14.2001	CINTAKARYA	7	3217030007	CINTAKARYA	1
8	32.17.14.2005	CICANGKANG-GIRANG	8	3217030008	CICANGKANG GIRANG	2
9	32.17.14.2008	PUNCAKSARI	9	3217030009	PUNCAKSARI	1
10	32.17.14.2007	PASIRPOGOR	10	3217030010	PASIRPOGOR	2
11	32.17.14.2002	SINDANGKER-TA	11	3217030011	SINDANGKER-TA	1

https://jabar.bps.go.id

Catatan :
*) 1. Perkotaan
2. Perdesaan

DAFTAR DESA/KELURAHAN

PROVINSI : [32] JAWA BARAT
KABUPATEN : [17] BANDUNG BARAT
KECAMATAN : [040] CILILIN

Data Kemendagri			MFD 2021 Semester 2			
No	Kode	Nama Desa	No	Kode	Nama Desa	Status*
1	32.17.11.2007	KARYAMUKTI	1	3217040001	KARYAMUKTI	2
2	32.17.11.2010	NANGGERANG	2	3217040002	NANGGERANG	2
3	32.17.11.2009	MUKAPAYUNG	3	3217040003	MUKAPAYUNG	1
4	32.17.11.2011	RANCA PANGGUNG	4	3217040004	RANCA PANGGUNG	1
5	32.17.11.2004	BONGAS	5	3217040005	BONGAS	1
6	32.17.11.2003	BATULAYANG	6	3217040006	BATULAYANG	2
7	32.17.11.2001	CILILIN	7	3217040007	CILILIN	1
8	32.17.11.2006	KARANGTAN-JUNG	8	3217040008	KARANGTAN-JUNG	1
9	32.17.11.2008	KIDANG-PANANJUNG	9	3217040010	KIDANG-PANANJUNG	2
10	32.17.11.2002	BUDIHARJA	10	3217040018	BUDIHARJA	1
11	32.17.11.2005	KARANG ANYAR	11	3217040019	KARANG ANYAR	2

Catatan :
*) 1. Perkotaan
2. Perdesaan

https://jabar.bps.go.id

PROVINSI : [32] JAWA BARAT
KABUPATEN : [17] BANDUNG BARAT
KECAMATAN : [050] CIHAMPELAS

Data Kemendagri			MFD 2021 Semester 2			
No	Kode	Nama Desa	No	Kode	Nama Desa	Status*
1	32.17.10.2008	SINGAJAYA	1	3217050009	SINGAJAYA	1
2	32.17.10.2009	TANJUNG-WANGI	2	3217050011	TANJUNG-WANGI	2
3	32.17.10.2007	SITUWANGI	3	3217050012	SITUWANGI	2
4	32.17.10.2006	PATARUMAN	4	3217050013	PATARUMAN	2
5	32.17.10.2001	CIPATIK	5	3217050014	CIPATIK	1
6	32.17.10.2002	CITAPEN	6	3217050015	CITAPEN	1
7	32.17.10.2003	CIHAMPELAS	7	3217050016	CIHAMPELAS	1
8	32.17.10.2005	MEKARMUKTI	8	3217050017	MEKARMUKTI	1
9	32.17.10.2010	TANJUNGJAYA	9	3217050020	TANJUNGJAYA	2
10	32.17.10.2004	MEKARJAYA	10	3217050021	MEKARJAYA	1

https://jabar.bps.go.id

Catatan :
*) 1. Perkotaan
2. Perdesaan

DAFTAR DESA/KELURAHAN

PROVINSI : [32] JAWA BARAT
KABUPATEN : [17] BANDUNG BARAT
KECAMATAN : [060] CIPONGKOR

Data Kemendagri			MFD 2021 Semester 2			
No	Kode	Nama Desa	No	Kode	Nama Desa	Status*
1	32.17.12.2007	CINTAASIH	1	3217060001	CINTAASIH	2
2	32.17.12.2010	KARANGSARI	2	3217060002	KARANGSARI	2
3	32.17.12.2012	NEGLASARI	3	3217060003	NEGLASARI	2
4	32.17.12.2009	GIRIMUKTI	4	3217060004	GIRIMUKTI	2
5	32.17.12.2004	CIJENUK	5	3217060005	CIJENUK	2
6	32.17.12.2008	CICANGKANG HILIR	6	3217060006	CICANGKANG HILIR	2
7	32.17.12.2014	SUKAMULYA	7	3217060007	SUKAMULYA	2
8	32.17.12.2003	CITALEM	8	3217060008	CITALEM	2
9	32.17.12.2011	MEKARSARI	9	3217060009	MEKARSARI	2
10	32.17.12.2001	SARINAGEN	10	3217060010	SARINAGEN	1
11	32.17.12.2006	CIBENDA	11	3217060011	CIBENDA	2
12	32.17.12.2005	CIJAMBU	12	3217060012	CIJAMBU	2
13	32.17.12.2013	SIRNAGALIH	13	3217060013	SIRNAGALIH	2
14	32.17.12.2002	BARANANG-SIANG	14	3217060014	BARANANG-SIANG	1

Catatan :
*) 1. Perkotaan
2. Perdesaan

https://jabar.bps.go.id

PROVINSI : [32] JAWA BARAT
KABUPATEN : [17] BANDUNG BARAT
KECAMATAN : [070] BATUJAJAR

Data Kemendagri			MFD 2021 Semester 2			
No	Kode	Nama Desa	No	Kode	Nama Desa	Status*
1	32.17.12.2007	SELACAU	1	3217070001	SELACAU	1
2	32.17.12.2002	BATUJAJAR BARAT	2	3217070002	BATUJAJAR BARAT	1
3	32.17.12.2001	BATUJAJAR TIMUR	3	3217070003	BATUJAJAR TIMUR	1
4	32.17.12.2010	GIRIASIH	4	3217070004	GIRIASIH	1
5	32.17.12.2004	GALANGGANG	5	3217070005	GALANGGANG	1
6	32.17.12.2008	PANGAUBAN	6	3217070006	PANGAUBAN	1
7	32.17.12.2005	CANGKORAH	7	3217070007	CANGKORAH	1

Catatan :
*) 1. Perkotaan
2. Perdesaan

https://jabar.bps.go.id

DAFTAR DESA/KELURAHAN

PROVINSI : [32] JAWA BARAT
KABUPATEN : [17] BANDUNG BARAT
KECAMATAN : [071] SAGULING

Data Kemendagri			MFD 2021 Semester 2			
No	Kode	Nama Desa	No	Kode	Nama Desa	Status*
1	32.17.16.2004	BOJONG HALEUANG	1	3217071001	BOJONG HALEUANG	2
2	32.17.16.2001	CIKANDE	2	3217071002	CIKANDE	2
3	32.17.16.2003	GIRIMUKTI	3	3217071003	GIRIMUKTI	2
4	32.17.16.2005	CIPANGERAN	4	3217071004	CIPANGERAN	2
5	32.17.16.2002	JATI	5	3217071005	JATI	2
6	32.17.16.2006	SAGULING	6	3217071006	SAGULING	2

Catatan :
*) 1. Perkotaan
2. Perdesaan

https://jabar.bps.go.id

PROVINSI : [32] JAWA BARAT
KABUPATEN : [17] BANDUNG BARAT
KECAMATAN : [080] CIPATAT

Data Kemendagri			MFD 2021 Semester 2			
No	Kode	Nama Desa	No	Kode	Nama Desa	Status*
1	32.17.07.2004	RAJAMANDA-LA KULON	1	3217080001	RAJAMANDA-LA KULON	1
2	32.17.07.2001	CIPTAHARJA	2	3217080002	CIPTAHARJA	1
3	32.17.07.2002	CIPATAT	3	3217080003	CIPATAT	1
4	32.17.07.2003	CITATAH	4	3217080004	CITATAH	2
5	32.17.07.2008	GUNUNGMA-SIGIT	5	3217080005	GUNUNGMA-SIGIT	2
6	32.17.07.2009	CIRAWAMEKAR	6	3217080006	CIRAWAMEKAR	2
7	32.17.07.2007	NYALINDUNG	7	3217080007	NYALINDUNG	2
8	32.17.07.2011	SUMURBAN DUNG	8	3217080008	SUMURBAN DUNG	2
9	32.17.07.2006	KERTAMUKTI	9	3217080009	KERTAMUKTI	2
10	32.17.07.2012	SARIMUKTI	10	3217080010	SARIMUKTI	1
11	32.17.07.2010	MANDALASARI	11	3217080011	MANDALASARI	1
12	32.17.07.2005	MANDALA-WANGI	12	3217080012	MANDALA-WANGI	1

Catatan :
*) 1. Perkotaan
2. Perdesaan

https://jabar.bps.go.id

DAFTAR DESA/KELURAHAN

PROVINSI : [32] JAWA BARAT
KABUPATEN : [17] BANDUNG BARAT
KECAMATAN : [090] PADALARANG

Data Kemendagri			MFD 2021 Semester 2			
No	Kode	Nama Desa	No	Kode	Nama Desa	Status*
1	32.17.08.2010	LAKSANA MEKAR	1	3217090001	LAKSANA MEKAR	1
2	32.17.08.2003	CIMERANG	2	3217090002	CIMERANG	2
3	32.17.08.2008	CIPEUNDEUY	3	3217090003	CIPEUNDEUY	1
4	32.17.08.2007	KERTAJAYA	4	3217090004	KERTAJAYA	1
5	32.17.08.2009	JAYAMEKAR	5	3217090005	JAYAMEKAR	1
6	32.17.08.2002	PADALARANG	6	3217090006	PADALARANG	1
7	32.17.08.2001	KERTAMULYA	7	3217090007	KERTAMULYA	1
8	32.17.08.2006	CIBURUY	8	3217090008	CIBURUY	1
9	32.17.08.2005	TAGOGAPU	9	3217090009	TAGOGAPU	1
10	32.17.08.2004	CAMPAKA MEKAR	10	3217090010	CEMPAKAME-KAR	1

Catatan :
*) 1. Perkotaan
2. Perdesaan

https://jabar.bps.go.id

PROVINSI : [32] JAWA BARAT
KABUPATEN : [17] BANDUNG BARAT
KECAMATAN : [100] NGAMPRAH

Data Kemendagri			MFD 2021 Semester 2			
No	Kode	Nama Desa	No	Kode	Nama Desa	Status*
1	32.17.06.2002	CIMAREME	1	3217100001	CIMAREME	1
2	32.17.06.2009	GADOBANG-KONG	2	3217100002	GADOBANG-KONG	1
3	32.17.06.2004	TANIMULYA	3	3217100003	TANIMULYA	1
4	32.17.06.2011	PAKUHAJI	4	3217100004	PAKUHAJI	1
5	32.17.06.2003	CILAME	5	3217100005	CILAME	1
6	32.17.06.2007	MARGAJAYA	6	3217100006	MARGAJAYA	1
7	32.17.06.2008	MEKARSARI	7	3217100007	MEKARSARI	1
8	32.17.06.2001	NGAMPRAH	8	3217100008	NGAMPRAH	1
9	32.17.06.2010	SUKATANI	9	3217100009	SUKATANI	1
10	32.17.06.2005	CIMANGGU	10	3217100010	CIMANGGU	2
11	32.17.06.2006	BOJONG-KONENG	11	3217100011	BOJONG-KONENG	2

Catatan :
*) 1. Perkotaan
2. Perdesaan

https://jabar.bps.go.id

DAFTAR DESA/KELURAHAN

PROVINSI : [32] JAWA BARAT
KABUPATEN : [17] BANDUNG BARAT
KECAMATAN : [110] PARONGPONG

Data Kemendagri			MFD 2021 Semester 2			
No	Kode	Nama Desa	No	Kode	Nama Desa	Status*
1	32.17.02.2005	CIWARUGA	1	3217110001	CIWARUGA	1
2	32.17.02.2004	CIHIDEUNG	2	3217110002	CIHIDEUNG	1
3	32.17.02.2006	CIGUGUR GIRANG	3	3217110003	CIGUGUR GIRANG	1
4	32.17.02.2007	SARIWANGI	4	3217110004	SARIWANGI	1
5	32.17.02.2002	CIHANJUANG	5	3217110005	CIHANJUANG	1
6	32.17.02.2003	CIHANJUANG RAHAYU	6	3217110006	CIHANJUANG RAHAYU	1
7	32.17.02.2001	KARYAWANGI	7	3217110007	KARYAWANGI	1

Catatan :
*) 1. Perkotaan
2. Perdesaan

https://jabar.bps.go.id

PROVINSI : [32] JAWA BARAT
KABUPATEN : [17] BANDUNG BARAT
KECAMATAN : [120] LEMBANG

Data Kemendagri			MFD 2021 Semester 2			
No	Kode	Nama Desa	No	Kode	Nama Desa	Status*
1	32.17.01.2007	GUDANG KAHURIPAN	1	3217120001	GUDANG KAHURIPAN	1
2	32.17.01.2016	WANGUNSARI	2	3217120002	WANGUNSARI	1
3	32.17.01.2001	PAGERWANGI	3	3217120003	PAGERWANGI	1
4	32.17.01.2011	MEKARWANGI	4	3217120004	MEKARWANGI	1
5	32.17.01.2010	LANGENSARI	5	3217120005	LANGENSARI	1
6	32.17.01.2002	KAYUAMBON	6	3217120006	KAYUAMBON	1
7	32.17.01.2003	LEMBANG	7	3217120007	LEMBANG	1
8	32.17.01.2005	CIKAHURIPAN	8	3217120008	CIKAHURIPAN	2
9	32.17.01.2013	SUKAJAYA	9	3217120009	SUKAJAYA	2
10	32.17.01.2008	JAYAGIRI	10	3217120010	JAYAGIRI	1
11	32.17.01.2012	CIBOGO	11	3217120011	CIBOGO	1
12	32.17.01.2006	CIKOLE	12	3217120012	CIKOLE	1
13	32.17.01.2004	CIKIDANG	13	3217120013	CIKIDANG	2
14	32.17.01.2015	WANGUN HARJA	14	3217120014	WANGUN HARJA	2
15	32.17.01.2009	CIBODAS	15	3217120015	CIBODAS	1
16	32.17.01.2014	SUNTENJAYA	16	3217120016	SUNTENJAYA	1

https://jabar.bps.go.id

Catatan :
*) 1. Perkotaan
2. Perdesaan

DAFTAR DESA/KELURAHAN

PROVINSI : [32] JAWA BARAT
KABUPATEN : [17] BANDUNG BARAT
KECAMATAN : [130] CISARUA

Data Kemendagri			MFD 2021 Semester 2			
No	Kode	Nama Desa	No	Kode	Nama Desa	Status*
1	32.17.03.2003	PASIRHALANG	1	3217130001	PASIRHALANG	2
2	32.17.03.2001	JAMBUDIPA	2	3217130002	JAMBUDIPA	1
3	32.17.03.2002	PADAASIH	3	3217130003	PADAASIH	2
4	32.17.03.2006	KERTAWANGI	4	3217130004	KERTAWANGI	1
5	32.17.03.2007	TUGUMUKTI	5	3217130005	TUGUMUKTI	2
6	32.17.03.2004	PASIRLANGU	6	3217130006	PASIRLANGU	2
7	32.17.03.2005	CIPADA	7	3217130007	CIPADA	2
8	32.17.03.2008	SADANG MEKAR	8	3217130008	SADANG MEKAR	2

Catatan :
*) 1. Perkotaan
2. Perdesaan

https://jabar.bps.go.id

PROVINSI : [32] JAWA BARAT
KABUPATEN : [17] BANDUNG BARAT
KECAMATAN : [140] CIKALONG WETAN

Data Kemendagri			MFD 2021 Semester 2			
No	Kode	Nama Desa	No	Kode	Nama Desa	Status*
1	32.17.04.2006	KANANGASARI	1	3217140001	KANANGASARI	1
2	32.17.04.2007	MANDALASARI	2	3217140002	MANDALASARI	2
3	32.17.04.2009	MEKARJAYA	3	3217140003	MEKARJAYA	2
4	32.17.04.2003	CIPADA	4	3217140004	CIPADA	2
5	32.17.04.2005	GANJARSARI	5	3217140005	GANJARSARI	2
6	32.17.04.2008	MANDALA-MUKTI	6	3217140006	MANDALA-MUKTI	1
7	32.17.04.2001	CIPTAGUMATI	7	3217140007	CIPTAGUMATI	1
8	32.17.04.2002	CIKALONG	8	3217140008	CIKALONG	1
9	32.17.04.2011	RENDE	9	3217140009	RENDE	2
10	32.17.04.2010	PUTERAN	10	3217140010	PUTERAN	2
11	32.17.04.2012	TENJOLAUT	11	3217140011	TENJOLAUT	2
12	32.17.04.2004	CISOMANG-BARAT	12	3217140012	CISOMANG BARAT	1
13	32.17.04.2013	WANGUNJAYA	13	3217140013	WANGUNJAYA	1

Catatan :
*) 1. Perkotaan
2. Perdesaan

https://jabar.bps.go.id

DAFTAR DESA/KELURAHAN

PROVINSI : [32] JAWA BARAT
KABUPATEN : [17] BANDUNG BARAT
KECAMATAN : [150] CIPEUNDEUY

Data Kemendagri			MFD 2021 Semester 2			
No	Kode	Nama Desa	No	Kode	Nama Desa	Status*
1	32.17.05.2007	MARGALUYU	1	3217150001	MARGALUYU	2
2	32.17.05.2008	NANGGELENG	2	3217150002	NANGGELENG	2
3	32.17.05.2010	SIRNARAJA	3	3217150003	SIRNARAJA	2
4	32.17.05.2005	JATIMEKAR	4	3217150004	JATIMEKAR	2
5	32.17.05.2003	BOJONGME-KAR	5	3217150005	BOJONGME-KAR	2
6	32.17.05.2009	NYENANG	6	3217150006	NYENANG	1
7	32.17.05.2001	CIPEUNDEUY	7	3217150007	CIPEUNDEUY	1
8	32.17.05.2006	MARGALAK-SANA	8	3217150008	MARGALAK-SANA	1
9	32.17.05.2012	SUKAHAJI	9	3217150009	SUKAHAJI	1
10	32.17.05.2002	CIHARASHAS	10	3217150010	CIHARASHAS	2
11	32.17.05.2011	SIRNAGALIH	11	3217150011	SIRNAGALIH	2
12	32.17.05.2004	CIROYOM	12	3217150012	CIROYOM	1

Catatan :
*) 1. Perkotaan
2. Perdesaan

https://jabar.bps.go.id

KABUPATEN PANGANDARAN

https://jabar.bps.go.id

https://jabar.bps.go.id

DAFTAR KECAMATAN

PROVINSI : [32] JAWA BARAT
KABUPATEN : [18] PANGANDARAN

Data Kemendagri			MFD 2021 Semester 2		
No	Kode	Nama Kecamatan	No	Kode	Nama Kecamatan
1	32.18.03	CIMERAK	1	3218010	CIMERAK
2	32.18.02	CIJULANG	2	3218020	CIJULANG
3	32.18.04	CIGUGUR	3	3218030	CIGUGUR
4	32.18.05	LANGKAPLANCAR	4	3218040	LANGKAPLANCAR
5	32.18.01	PARIGI	5	3218050	PARIGI
6	32.18.10	SIDAMULIH	6	3218060	SIDAMULIH
7	32.18.09	PANGANDARAN	7	3218070	PANGANDARAN
8	32.18.08	KALIPUCANG	8	3218080	KALIPUCANG
9	32.18.07	PADAHERANG	9	3218090	PADAHERANG
10	32.18.06	MANGUNJAYA	10	3218100	MANGUNJAYA

https://jabar.bps.go.id

JUMLAH DESA/KELURAHAN PER KECAMATAN

PROVINSI : [32] JAWA BARAT
KABUPATEN : [18] PANGANDARAN

Data Kemendagri				MFD 2021 Semester 2			
No	Kode	Nama Kecamatan	Jml Desa	No	Kode	Nama Kecamatan	Jml Desa
1	32.18.03	CIMERAK	11	1	3218010	CIMERAK	11
2	32.18.02	CIJULANG	7	2	3218020	CIJULANG	7
3	32.18.04	CIGUGUR	7	3	3218030	CIGUGUR	7
4	32.18.05	LANGKAPLANCAR	15	4	3218040	LANGKAPLANCAR	15
5	32.18.01	PARIGI	10	5	3218050	PARIGI	10
6	32.18.10	SIDAMULIH	7	6	3218060	SIDAMULIH	7
7	32.18.09	PANGANDARAN	8	7	3218070	PANGANDARAN	8
8	32.18.08	KALIPUCANG	9	8	3218080	KALIPUCANG	9
9	32.18.07	PADAHERANG	14	9	3218090	PADAHERANG	14
10	32.18.06	MANGUNJAYA	5	10	3218100	MANGUNJAYA	5

https://jabar.bps.go.id

PROVINSI : [32] JAWA BARAT
KABUPATEN : [18] PANGANDARAN
KECAMATAN : [010] CIMERAK

Data Kemendagri			MFD 2021 Semester 2			
No	Kode	Nama Desa	No	Kode	Nama Desa	Status*
1	32.18.03.2007	KERTAMUKTI	1	3218010001	KERTAMUKTI	2
2	32.18.03.2002	CIPARANTI	2	3218010002	CIPARANTI	2
3	32.18.03.2003	LEGOKJAWA	3	3218010003	LEGOKJAWA	2
4	32.18.03.2004	MASAWAH	4	3218010004	MASAWAH	2
5	32.18.03.2009	BATAMALANG	5	3218010005	BATAMALANG	2
6	32.18.03.2005	CIMERAK	6	3218010006	CIMERAK	2
7	32.18.03.2011	LIMUSGEDE	7	3218010007	LIMUSGEDE	2
8	32.18.03.2001	KERTAHARJA	8	3218010008	KERTAHARJA	2
9	32.18.03.2010	MEKARSARI	9	3218010009	MEKARSARI	2
10	32.18.03.2008	SINDANGSARI	10	3218010010	SINDANGSARI	2
11	32.18.03.2006	SUKAJAYA	11	3218010011	SUKAJAYA	2

https://jabar.bps.go.id

Catatan :
*) 1. Perkotaan
2. Perdesaan

DAFTAR DESA/KELURAHAN

PROVINSI : [32] JAWA BARAT
KABUPATEN : [18] PANGANDARAN
KECAMATAN : [020] CIJULANG

Data Kemendagri			MFD 2021 Semester 2			
No	Kode	Nama Desa	No	Kode	Nama Desa	Status*
1	32.18.02.2002	CIAKAR	1	3218020001	CIAKAR	2
2	32.18.02.2003	CIBANTEN	2	3218020002	CIBANTEN	2
3	32.18.02.2004	KERTAYASA	3	3218020003	KERTAYASA	2
4	32.18.02.2001	BATUKARAS	4	3218020004	BATUKARAS	2
5	32.18.02.2005	CIJULANG	5	3218020005	CIJULANG	1
6	32.18.02.2006	KONDANG JAJAR	6	3218020006	KONDANG JAJAR	1
7	32.18.02.2007	MARGACINTA	7	3218020007	MARGACINTA	2

Catatan :
*) 1. Perkotaan
2. Perdesaan

https://jabar.bps.go.id

PROVINSI : [32] JAWA BARAT
KABUPATEN : [18] PANGANDARAN
KECAMATAN : [030] CIGUGUR

Data Kemendagri			MFD 2021 Semester 2			
No	Kode	Nama Desa	No	Kode	Nama Desa	Status*
1	32.18.04.2004	KERTAJAYA	1	3218030001	KERTAJAYA	2
2	32.18.04.2005	BUNISARI	2	3218030002	BUNISARI	2
3	32.18.04.2002	CIMINDI	3	3218030003	CIMINDI	2
4	32.18.04.2001	CIGUGUR	4	3218030004	CIGUGUR	2
5	32.18.04.2006	CAMPAKA	5	3218030005	CAMPAKA	2
6	32.18.04.2003	PAGERBUMI	6	3218030006	PAGERBUMI	2
7	32.18.04.2007	HARUM MAN-DALA	7	3218030007	HARUM MAN-DALA	2

Catatan :
*) 1. Perkotaan
2. Perdesaan

https://jabar.bps.go.id

DAFTAR DESA/KELURAHAN

PROVINSI : [32] JAWA BARAT
KABUPATEN : [18] PANGANDARAN
KECAMATAN : [040] LANGKAPLANCAR

Data Kemendagri			MFD 2021 Semester 2			
No	Kode	Nama Desa	No	Kode	Nama Desa	Status*
1	32.18.05.2008	JADIMULYA	1	3218040001	JADIMULYA	2
2	32.18.05.2011	BANGUN KARYA	2	3218040002	BANGUN KARYA	2
3	32.18.05.2012	SUKAMULYA	3	3218040003	SUKAMULYA	2
4	32.18.05.2009	JADIKARYA	4	3218040004	JADIKARYA	2
5	32.18.05.2015	BUNGURRAYA	5	3218040005	BUNGURRAYA	2
6	32.18.05.2010	BOJONG	6	3218040006	BOJONG	2
7	32.18.05.2001	KARANGKA-MIRI	7	3218040007	KARANGKA-MIRI	2
8	32.18.05.2014	CISARUA	8	3218040008	CISARUA	2
9	32.18.05.2002	CIMANGGU	9	3218040009	CIMANGGU	2
10	32.18.05.2006	BANGUNJAYA	10	3218040010	BANGUNJAYA	2
11	32.18.05.2003	LANGKAPLAN-CAR	11	3218040011	LANGKAPLAN-CAR	2
12	32.18.05.2007	JAYASARI	12	3218040012	JAYASARI	2
13	32.18.05.2004	PANGKALAN	13	3218040013	PANGKALAN	2
14	32.18.05.2005	BOJONG KONDANG	14	3218040014	BOJONG KONDANG	2
15	32.18.05.2013	MEKARWANGI	15	3218040015	MEKARWANGI	2

Catatan :
*) 1. Perkotaan
2. Perdesaan

https://jabar.bps.go.id

PROVINSI : [32] JAWA BARAT
KABUPATEN : [18] PANGANDARAN
KECAMATAN : [050] PARIGI

Data Kemendagri			MFD 2021 Semester 2			
No	Kode	Nama Desa	No	Kode	Nama Desa	Status*
1	32.18.01.2007	KARANG JALADRI	1	3218050001	KARANG JALADRI	1
2	32.18.01.2001	PARIGI	2	3218050002	PARIGI	1
3	32.18.01.2002	KARANGBEN-DA	3	3218050003	KARANGBEN-DA	1
4	32.18.01.2003	CILIANG	4	3218050004	CILIANG	2
5	32.18.01.2008	CIBENDA	5	3218050005	CIBENDA	2
6	32.18.01.2004	BOJONG	6	3218050006	BOJONG	2
7	32.18.01.2006	SELASARI	7	3218050007	SELASARI	2
8	32.18.01.2005	CINTARATU	8	3218050008	CINTARATU	2
9	32.18.01.2009	CINTAKARYA	9	3218050009	CINTAKARYA	2
10	32.18.01.2010	PARAKAN-MANGGU	10	3218050010	PARAKAN-MANGGU	2

Catatan :
*) 1. Perkotaan
2. Perdesaan

https://jabar.bps.go.id

DAFTAR DESA/KELURAHAN

PROVINSI : [32] JAWA BARAT
KABUPATEN : [18] PANGANDARAN
KECAMATAN : [060] SIDAMULIH

Data Kemendagri			MFD 2021 Semester 2			
No	Kode	Nama Desa	No	Kode	Nama Desa	Status*
1	32.18.10.2003	SUKARESIK	1	3218060001	SUKARESIK	2
2	32.18.10.2004	CIKEMBULAN	2	3218060002	CIKEMBULAN	1
3	32.18.10.2005	PAJATEN	3	3218060003	PAJATEN	2
4	32.18.10.2001	SIDAMULIH	4	3218060004	SIDAMULIH	2
5	32.18.10.2002	CIKALONG	5	3218060005	CIKALONG	2
6	32.18.10.2006	KERSARATU	6	3218060006	KERSARATU	2
7	32.18.10.2007	KALIJATI	7	3218060007	KALIJATI	2

Catatan :
*) 1. Perkotaan
2. Perdesaan

https://jabar.bps.go.id

PROVINSI : [32] JAWA BARAT
KABUPATEN : [18] PANGANDARAN
KECAMATAN : [070] PANGANDARAN

Data Kemendagri			MFD 2021 Semester 2			
No	Kode	Nama Desa	No	Kode	Nama Desa	Status*
1	32.18.09.2005	WONOHARJO	1	3218070001	WONOHARJO	1
2	32.18.09.2007	PANANJUNG	2	3218070002	PANANJUNG	1
3	32.18.09.2004	PANGANDA-RAN	3	3218070003	PANGANDA-RAN	1
4	32.18.09.2001	BABAKAN	4	3218070004	BABAKAN	1
5	32.18.09.2002	SUKAHURIP	5	3218070005	SUKAHURIP	2
6	32.18.09.2003	PURBAHAYU	6	3218070006	PURBAHAYU	2
7	32.18.09.2006	SIDOMULYO	7	3218070007	SIDOMULYO	2
8	32.18.09.2008	PAGER-GUNUNG	8	3218070008	PAGER-GUNUNG	2

Catatan :
*) 1. Perkotaan
2. Perdesaan

https://jabar.bps.go.id

DAFTAR DESA/KELURAHAN

PROVINSI : [32] JAWA BARAT
KABUPATEN : [18] PANGANDARAN
KECAMATAN : [080] KALIPUCANG

Data Kemendagri			MFD 2021 Semester 2			
No	Kode	Nama Desa	No	Kode	Nama Desa	Status*
1	32.18.08.2001	PUTRAPING-GAN	1	3218080001	PUTRAPING-GAN	2
2	32.18.08.2002	EMPLAK	2	3218080002	EMPLAK	2
3	32.18.08.2003	BALOGO	3	3218080003	BAGOLO	2
4	32.18.08.2004	PAMOTAN	4	3218080004	PAMOTAN	2
5	32.18.08.2005	KALIPUCANG	5	3218080005	KALIPUCANG	1
6	32.18.08.2006	CIBULUH	6	3218080006	CIBULUH	2
7	32.18.08.2007	BANJARHARJA	7	3218080007	BANJARHARJA	2
8	32.18.08.2008	TUNGGILIS	8	3218080008	TUNGGILIS	2
9	32.18.08.2009	CIPARAKAN	9	3218080009	CIPARAKAN	2

Catatan :
*) 1. Perkotaan
2. Perdesaan

https://jabar.bps.go.id

PROVINSI : [32] JAWA BARAT
KABUPATEN : [18] PANGANDARAN
KECAMATAN : [090] PADAHERANG

Data Kemendagri			MFD 2021 Semester 2			
No	Kode	Nama Desa	No	Kode	Nama Desa	Status*
1	32.18.07.2001	PANYUTRAN	1	3218090001	PANYUTRAN	2
2	32.18.07.2011	BOJONGSARI	2	3218090002	BOJONGSARI	2
3	32.18.07.2002	CIGANJENG	3	3218090003	CIGANJENG	2
4	32.18.07.2004	SUKANAGARA	4	3218090004	SUKANAGARA	2
5	32.18.07.2012	SINDANG WANGI	5	3218090005	SINDANG WANGI	2
6	32.18.07.2003	KARANGSARI	6	3218090006	KARANGSARI	2
7	32.18.07.2005	PALEDAH	7	3218090007	PALEDAH	2
8	32.18.07.2013	MARUYUNG-SARI	8	3218090008	MARUYUNG-SARI	2
9	32.18.07.2006	KARANG PAWITAN	9	3218090009	KARANG PAWITAN	2
10	32.18.07.2007	PADAHERANG	10	3218090010	PADAHERANG	1
11	32.18.07.2008	KEDUNGWU-LUH	11	3218090011	KEDUNGWU-LUH	2
12	32.18.07.2014	KARANG MULYA	12	3218090012	KARANG MULYA	2
13	32.18.07.2009	CIBOGO	13	3218090013	CIBOGO	2
14	32.18.07.2010	PASIRGEULIS	14	3218090014	PASIRGEULIS	2

Catatan :
*) 1. Perkotaan
2. Perdesaan

https://jabar.bps.go.id

DAFTAR DESA/KELURAHAN

PROVINSI : [32] JAWA BARAT
KABUPATEN : [18] PANGANDARAN
KECAMATAN : [100] WANGUNJAYA

Data Kemendagri			MFD 2021 Semester 2			
No	Kode	Nama Desa	No	Kode	Nama Desa	Status*
1	32.18.06.2001	SUKAMAJU	1	3218100001	SUKAMAJU	2
2	32.18.06.2002	KERTAJAYA	2	3218100002	KERTAJAYA	2
3	32.18.06.2003	MANGUNJAYA	3	3218100003	MANGUNJAYA	2
4	32.18.06.2005	JANGRAGA	4	3218100004	JANGRAGA	2
5	32.18.06.2004	SINDANGJAYA	5	3218100005	SINDANGJAYA	2

Catatan :
*) 1. Perkotaan
2. Perdesaan

https://jabar.bps.go.id

KOTA BOGOR

https://jabar.bps.go.id

https://jabar.bps.go.id

PROVINSI : [32] JAWA BARAT
KOTA : [71] BOGOR

Data Kemendagri			MFD 2021 Semester 2		
No	Kode	Nama Kecamatan	No	Kode	Nama Kecamatan
1	32.71.01	BOGOR SELATAN	1	3271010	BOGOR SELATAN
2	32.71.02	BOGOR TIMUR	2	3271020	BOGOR TIMUR
3	32.71.05	BOGOR UTARA	3	3271030	BOGOR UTARA
4	32.71.03	BOGOR TENGAH	4	3271040	BOGOR TENGAH
5	32.71.04	BOGOR BARAT	5	3271050	BOGOR BARAT
6	32.71.06	TANAH SAREAL	6	3271060	TANAH SEREAL

https://jabar.bps.go.id

JUMLAH DESA/KELURAHAN PER KECAMATAN

PROVINSI : [32] JAWA BARAT
KOTA : [71] BOGOR

Data Kemendagri				MFD 2021 Semester 2			
No	Kode	Nama Kecamatan	Jml Kel.	No	Kode	Nama Kecamatan	Jml Kel.
1	32.71.01	BOGOR SELATAN	16	1	3271010	BOGOR SELATAN	16
2	32.71.02	BOGOR TIMUR	6	2	3271020	BOGOR TIMUR	6
3	32.71.05	BOGOR UTARA	8	3	3271030	BOGOR UTARA	8
4	32.71.03	BOGOR TENGAH	11	4	3271040	BOGOR TENGAH	11
5	32.71.04	BOGOR BARAT	16	5	3271050	BOGOR BARAT	16
6	32.71.06	TANAH SAREAL	11	6	3271060	TANAH SEREAL	11

https://jabar.bps.go.id

PROVINSI : [32] JAWA BARAT
KOTA : [71] BOGOR
KECAMATAN : [010] BOGOR SELATAN

Data Kemendagri			MFD 2021 Semester 2			
No	Kode	Nama Kelurahan	No	Kode	Nama Kelurahan	Status*
1	32.71.01.1007	MULYAHARJA	1	3271010001	MULYAHARJA	1
2	32.71.01.1005	PAMOYANAN	2	3271010002	PAMOYANAN	1
3	32.71.01.1006	RANGGA MEKAR	3	3271010003	RANGGA MEKAR	1
4	32.71.01.1014	GENTENG	4	3271010004	GENTENG	1
5	32.71.01.1011	KERTAMAYA	5	3271010005	KERTAMAYA	1
6	32.71.01.1010	RANCAMAYA	6	3271010006	RANCAMAYA	1
7	32.71.01.1009	BOJONGKERTA	7	3271010007	BOJONGKERTA	1
8	32.71.01.1012	HARJASARI	8	3271010008	HARJASARI	1
9	32.71.01.1013	MUARASARI	9	3271010009	MUARASARI	1
10	32.71.01.1015	PAKUAN	10	3271010010	PAKUAN	1
11	32.71.01.1016	CIPAKU	11	3271010011	CIPAKU	1
12	32.71.01.1004	LAWANGGIN-TUNG	12	3271010012	LAWANGGIN-TUNG	1
13	32.71.01.1001	BATUTULIS	13	3271010013	BATUTULIS	1
14	32.71.01.1002	BONDONGAN	14	3271010014	BONDONGAN	1
15	32.71.01.1003	EMPANG	15	3271010015	EMPANG	1
16	32.71.01.1008	CIKARET	16	3271010016	CIKARET	1

Catatan :
*) 1. Perkotaan
2. Perdesaan

https://jabar.bps.go.id

DAFTAR DESA/KELURAHAN

PROVINSI : [32] JAWA BARAT
KOTA : [71] BOGOR
KECAMATAN : [020] BOGOR TIMUR

Data Kemendagri			MFD 2021 Semester 2			
No	Kode	Nama Kelurahan	No	Kode	Nama Kelurahan	Status*
1	32.71.02.1004	SINDANGSARI	1	3271020001	SINDANGSARI	1
2	32.71.02.1005	SINDANGRASA	2	3271020002	SINDANGRASA	1
3	32.71.02.1006	TAJUR	3	3271020003	TAJUR	1
4	32.71.02.1003	KATULAMPA	4	3271020004	KATULAMPA	1
5	32.71.02.1002	BARANANG-SIANG	5	3271020005	BARANANG-SIANG	1
6	32.71.02.1001	SUKASARI	6	3271020006	SUKASARI	1

Catatan :
*) 1. Perkotaan
2. Perdesaan

https://jabar.bps.go.id

PROVINSI : [32] JAWA BARAT
KOTA : [71] BOGOR
KECAMATAN : [030] BOGOR UTARA

Data Kemendagri			MFD 2021 Semester 2			
No	Kode	Nama Kelurahan	No	Kode	Nama Kelurahan	Status*
1	32.71.05.1001	BANTARJATI	1	3271030001	BANTARJATI	1
2	32.71.05.1002	TEGALGUNDIL	2	3271030002	TEGALGUNDIL	1
3	32.71.05.1007	TANAHBARU	3	3271030003	TANAHBARU	1
4	32.71.05.1008	CIHAMPAR	4	3271030004	CIHAMPAR	1
5	32.71.05.1006	CILUAR	5	3271030005	CILUAR	1
6	32.71.05.1005	CIBULUH	6	3271030006	CIBULUH	1
7	32.71.05.1003	KEDUNG HALANG	7	3271030007	KEDUNG HALANG	1
8	32.71.05.1004	CIPARIGI	8	3271030008	CIPARIGI	1

https://jabar.bps.go.id

Catatan :
*) 1. Perkotaan
2. Perdesaan

DAFTAR DESA/KELURAHAN

PROVINSI : [32] JAWA BARAT
KOTA : [71] BOGOR
KECAMATAN : [040] BOGOR TENGAH

Data Kemendagri			MFD 2021 Semester 2			
No	Kode	Nama Kelurahan	No	Kode	Nama Kelurahan	Status*
1	32.71.03.1002	PALEDANG	1	3271040001	PALEDANG	1
2	32.71.03.1001	GUDANG	2	3271040002	GUDANG	1
3	32.71.03.1008	BABAKAN PASAR	3	3271040003	BABAKAN PASAR	1
4	32.71.03.1007	TEGALLEGA	4	3271040004	TEGALLEGA	1
5	32.71.03.1005	BABAKAN	5	3271040005	BABAKAN	1
6	32.71.03.1006	SEMPUR	6	3271040006	SEMPUR	1
7	32.71.03.1003	PABATON	7	3271040007	PABATON	1
8	32.71.03.1004	CIBOGOR	8	3271040008	CIBOGOR	1
9	32.71.03.1009	PANARANGAN	9	3271040009	PANARANGAN	1
10	32.71.03.1011	KEBONKELAPA	10	3271040010	KEBONKELAPA	1
11	32.71.03.1010	CIWARINGIN	11	3271040011	CIWARINGIN	1

Catatan :
*) 1. Perkotaan
2. Perdesaan

https://jabar.bps.go.id

PROVINSI : [32] JAWA BARAT
KOTA : [71] BOGOR
KECAMATAN : [050] BOGOR BARAT

Data Kemendagri			MFD 2021 Semester 2			
No	Kode	Nama Kelurahan	No	Kode	Nama Kelurahan	Status*
1	32.71.04.1014	PASIRMULYA	1	3271050001	PASIRMULYA	1
2	32.71.04.1013	PASIRKUDA	2	3271050002	PASIRKUDA	1
3	32.71.04.1012	PASIRJAYA	3	3271050003	PASIRJAYA	1
4	32.71.04.1015	GUNUNGBATU	4	3271050004	GUNUNGBATU	1
5	32.71.04.1016	LOJI	5	3271050005	LOJI	1
6	32.71.04.1001	MENTENG	6	3271050006	MENTENG	1
7	32.71.04.1009	CILENDEK TIMUR	7	3271050007	CILENDEK TIMUR	1
8	32.71.04.1008	CILENDEK BARAT	8	3271050008	CILENDEK BARAT	1
9	32.71.04.1002	SINDANGBA-RANG	9	3271050009	SINDANGBA-RANG	1
10	32.71.04.1004	MARGAJAYA	10	3271050010	MARGAJAYA	1
11	32.71.04.1005	BALUNGBANG-JAYA	11	3271050011	BALUNGBANG-JAYA	1
12	32.71.04.1006	SITUGEDE	12	3271050012	SITUGEDE	1
13	32.71.04.1003	BUBULAK	13	3271050013	BUBULAK	1
14	32.71.04.1007	SEMPLAK	14	3271050014	SEMPLAK	1
15	32.71.04.1010	CURUGMEKAR	15	3271050015	CURUGMEKAR	1
16	32.71.04.1011	CURUG	16	3271050016	CURUG	1

Catatan :
*) 1. Perkotaan
2. Perdesaan

https://jabar.bps.go.id

DAFTAR DESA/KELURAHAN

PROVINSI : [32] JAWA BARAT
KOTA : [71] BOGOR
KECAMATAN : [060] TANAH SEREAL

Data Kemendagri			MFD 2021 Semester 2			
No	Kode	Nama Kelurahan	No	Kode	Nama Kelurahan	Status*
1	32.71.06.1005	KEDUNG WA RINGIN	1	3271060001	KEDUNG WARINGIN	1
2	32.71.06.1006	KEDUNG JAYA	2	3271060002	KEDUNGJAYA	1
3	32.71.06.1002	KEBON PEDES	3	3271060003	KEBONPEDES	1
4	32.71.06.1001	TANAH SAR-EAL	4	3271060004	TANAHSEREAL	1
5	32.71.06.1003	KEDUNG BADAK	5	3271060005	KEDUNG BADAK	1
6	32.71.06.1004	SUKARESMI	6	3271060006	SUKARESMI	1
7	32.71.06.1007	SUKADAMAI	7	3271060007	SUKADAMAI	1
8	32.71.06.1011	CIBADAK	8	3271060008	CIBADAK	1
9	32.71.06.1010	KAYUMANIS	9	3271060009	KAYUMANIS	1
10	32.71.06.1008	MEKAR WANGI	10	3271060010	MEKARWANGI	1
11	32.71.06.1009	KENCANA	11	3271060011	KENCANA	1

Catatan :
*) 1. Perkotaan
2. Perdesaan

https://jabar.bps.go.id

KOTA SUKABUMI

https://jabar.bps.go.id

https://jabar.bps.go.id

PROVINSI : [32] JAWA BARAT
KOTA : [72] SUKABUMI

Data Kemendagri			MFD 2021 Semester 2		
No	Kode	Nama Kecamatan	No	Kode	Nama Kecamatan
1	32.72.05	BAROS	1	3272010	BAROS
2	32.72.06	LEMBURSITU	2	3272011	LEMBURSITU
3	32.72.07	CIBEUREUM	3	3272012	CIBEUREUM
4	32.72.03	CITAMIANG	4	3272020	CITAMIANG
5	32.72.04	WARUDOYONG	5	3272030	WARUDOYONG
6	32.72.01	GUNUNGPUYUH	6	3272040	GUNUNG PUYUH
7	32.72.02	CIKOLE	7	3272050	CIKOLE

https://jabar.bps.go.id

JUMLAH DESA/KELURAHAN PER KECAMATAN

PROVINSI : [32] JAWA BARAT
KOTA : [72] SUKABUMI

Data Kemendagri				MFD 2021 Semester 2			
No	Kode	Nama Kecamatan	Jml Kel.	No	Kode	Nama Kecamatan	Jml Kel.
1	32.72.05	BAROS	4	1	3272010	BAROS	4
2	32.72.06	LEMBURSITU	5	2	3272011	LEMBURSITU	5
3	32.72.07	CIBEUREUM	4	3	3272012	CIBEUREUM	4
4	32.72.03	CITAMIANG	5	4	3272020	CITAMIANG	5
5	32.72.04	WARUDOYONG	5	5	3272030	WARUDOYONG	5
6	32.72.01	GUNUNGPUYUH	4	6	3272040	GUNUNG PUYUH	4
7	32.72.02	CIKOLE	6	7	3272050	CIKOLE	6

https://jabar.bps.go.id

PROVINSI : [32] JAWA BARAT
KOTA : [72] SUKABUMI
KECAMATAN : [010] BAROS

Data Kemendagri			MFD 2021 Semester 2			
No	Kode	Nama Kelurahan	No	Kode	Nama Kelurahan	Status*
1	32.72.05.1004	SINDANGJAYA HILIR	1	3272010006	SINDANGJAYA HILIR	1
2	32.72.05.1003	JAYAMEKAR	2	3272010007	JAYAMEKAR	1
3	32.72.05.1002	JAYARAKSA	3	3272010008	JAYARAKSA	1
4	32.72.05.1001	BAROS	4	3272010009	BAROS	1

Catatan :
*) 1. Perkotaan
2. Perdesaan

https://jabar.bps.go.id

PROVINSI : [32] JAWA BARAT
KOTA : [72] SUKABUMI
KECAMATAN : [011] LEMBURSITU

Data Kemendagri			MFD 2021 Semester 2			
No	Kode	Nama Kelurahan	No	Kode	Nama Kelurahan	Status*
1	32.72.06.1003	LEMBURSITU	1	3272011001	LEMBURSITU	1
2	32.72.06.1002	SITUMEKAR	2	3272011002	SITUMEKAR	1
3	32.72.06.1001	CIPANENGAH	3	3272011003	CIPANENGAH	1
4	32.72.06.1004	CIKUNDUL	4	3272011004	CIKUNDUL	1
5	32.72.06.1005	SINDANGSARI	5	3272011005	SINDANGSARI	1

Catatan :
*) 1. Perkotaan
2. Perdesaan

PROVINSI : [32] JAWA BARAT
KOTA : [72] SUKABUMI
KECAMATAN : [012] CIBEUREUM

Data Kemendagri			MFD 2021 Semester 2			
No	Kode	Nama Kelurahan	No	Kode	Nama Kelurahan	Status*
1	32.72.07.1003	SINDANG PALAY	1	3272012001	SINDANG PALAY	1
2	32.72.07.1004	LIMUSNUNG-GAL	2	3272012002	LIMUSNUNG-GAL	1
3	32.72.07.1002	BABAKAN	3	3272012003	BABAKAN	1
4	32.72.07.1001	CIBEUREUM HILIR	4	3272012004	CIBEUREUM HILIR	1

Catatan :
*) 1. Perkotaan
2. Perdesaan

PROVINSI : [32] JAWA BARAT
KOTA : [72] SUKABUMI
KECAMATAN : [020] CITAMIANG

Data Kemendagri			MFD 2021 Semester 2			
No	Kode	Nama Kelurahan	No	Kode	Nama Kelurahan	Status*
1	32.72.03.1005	CIKONDANG	1	3272020001	CIKONDANG	1
2	32.72.03.1004	GEDONG PANJANG	2	3272020002	GEDONG PANJANG	1
3	32.72.03.1001	CITAMIANG	3	3272020003	CITAMIANG	1
4	32.72.03.1003	NANGGELENG	4	3272020004	NANGGELENG	1
5	32.72.03.1002	TIPAR	5	3272020005	TIPAR	1

Catatan :
*) 1. Perkotaan
2. Perdesaan

https://jabar.bps.go.id

PROVINSI : [32] JAWA BARAT
KOTA : [72] SUKABUMI
KECAMATAN : [030] WARUDOYONG

Data Kemendagri			MFD 2021 Semester 2			
No	Kode	Nama Kelurahan	No	Kode	Nama Kelurahan	Status*
1	32.72.04.1003	DAYEUH LUHUR	1	3272030001	DAYEUH LUHUR	1
2	32.72.04.1001	WARU DOYONG	2	3272030002	WARU DOYONG	1
3	32.72.04.1002	NYOMPLONG	3	3272030003	NYOMPLONG	1
4	32.72.04.1005	BENTENG	4	3272030004	BENTENG	1
5	32.72.04.1004	SUKAKARYA	5	3272030005	SUKAKARYA	1

Catatan :
*) 1. Perkotaan
2. Perdesaan

https://jabar.bps.go.id

PROVINSI : [32] JAWA BARAT
KOTA : [72] SUKABUMI
KECAMATAN : [040] GUNUNG PUYUH

Data Kemendagri			MFD 2021 Semester 2			
No	Kode	Nama Kelurahan	No	Kode	Nama Kelurahan	Status*
1	32.72.01.1004	KARANG TENGAH	1	3272040001	KARANG TENGAH	1
2	32.72.01.1001	GUNUNG PUYUH	2	3272040002	GUNUNG PUYUH	1
3	32.72.01.1003	SRIWIDARI	3	3272040003	SRIWIDARI	1
4	32.72.01.1002	KARAMAT	4	3272040004	KARAMAT	1

Catatan :
*) 1. Perkotaan
2. Perdesaan

DAFTAR DESA/KELURAHAN

PROVINSI : [32] JAWA BARAT
KOTA : [72] SUKABUMI
KECAMATAN : [050] CIKOLE

Data Kemendagri			MFD 2021 Semester 2			
No	Kode	Nama Kelurahan	No	Kode	Nama Kelurahan	Status*
1	32.72.02.1003	GUNUNG PARANG	1	3272050001	GUNUNG PARANG	1
2	32.72.02.1004	KEBONJATI	2	3272050002	KEBONJATI	1
3	32.72.02.1001	CIKOLE	3	3272050003	CIKOLE	1
4	32.72.02.1002	SELABATU	4	3272050004	SELABATU	1
5	32.72.02.1005	CISARUA	5	3272050005	CISARUA	1
6	32.72.02.1006	SUBANGJAYA	6	3272050006	SUBANGJAYA	1

Catatan :
*) 1. Perkotaan
2. Perdesaan

https://jabar.bps.go.id

KOTA BANDUNG

https://jabar.bps.go.id

https://jabar.bps.go.id

PROVINSI : [32] JAWA BARAT
KOTA : [73] BANDUNG

Data Kemendagri			MFD 2021 Semester 2		
No	Kode	Nama Kecamatan	No	Kode	Nama Kecamatan
1	32.73.15	BANDUNG KULON	1	3273010	BANDUNG KULON
2	32.73.03	BABAKAN CIPARAY	2	3273020	BABAKAN CIPARAY
3	32.73.04	BOJONGLOA KALER	3	3273030	BOJONGLOA KALER
4	32.73.17	BOJONGLOA KIDUL	4	3273040	BOJONGLOA KIDUL
5	32.73.10	ASTANA ANYAR	5	3273050	ASTANA ANYAR
6	32.73.11	REGOL	6	3273060	REGOL
7	32.73.13	LENGKONG	7	3273070	LENGKONG
8	32.73.21	BANDUNG KIDUL	8	3273080	BANDUNG KIDUL
9	32.73.22	BUAHBATU	9	3273090	BUAHBATU
10	32.73.23	RANCASARI	10	3273100	RANCASARI
11	32.73.27	GEDEBAGE	11	3273101	GEDEBAGE
12	32.73.25	CIBIRU	12	3273110	CIBIRU
13	32.73.28	PANYILEUKAN	13	3273111	PANYILEUKAN
14	32.73.26	UJUNGBERUNG	14	3273120	UJUNG BERUNG
15	32.73.29	CINAMBO	15	3273121	CINAMBO
16	32.73.24	ARCAMANIK	16	3273130	ARCAMANIK
17	32.73.20	ANTAPANI	17	3273141	ANTAPANI
18	32.73.30	MANDALAJATI	18	3273142	MANDALAJATI
19	32.73.16	KIARACONDONG	19	3273150	KIARA CONDONG
20	32.73.12	BATUNUNGGAL	20	3273160	BATUNUNGGAL
21	32.73.19	SUMUR BANDUNG	21	3273170	SUMUR BANDUNG
22	32.73.05	ANDIR	22	3273180	ANDIR

https://jabar.bps.go.id

DAFTAR KECAMATAN

PROVINSI : [32] JAWA BARAT
KOTA : [73] BANDUNG

Data Kemendagri			MFD 2021 Semester 2		
No	Kode	Nama Kecamatan	No	Kode	Nama Kecamatan
23	32.73.06	CICENDO	23	3273190	CICENDO
24	32.73.09	BANDUNG WETAN	24	3273200	BANDUNG WETAN
25	32.73.14	CIBEUNYING KIDUL	25	3273210	CIBEUNYING KIDUL
26	32.73.18	CIBEUNYING KALER	26	3273220	CIBEUNYING KALER
27	32.73.02	COBLONG	27	3273230	COBLONG
28	32.73.07	SUKAJADI	28	3273240	SUKAJADI
29	32.73.01	SUKASARI	29	3273260	SUKASARI
30	32.73.08	CIDADAP	30	3273260	CIDADAP

https://jabar.bps.go.id

JUMLAH DESA/KELURAHAN PER KECAMATAN

PROVINSI : [32] JAWA BARAT
KOTA : [73] BANDUNG

Data Kemendagri				MFD 2021 Semester 2			
No	Kode	Nama Kecamatan	Jml Kel.	No	Kode	Nama Kecamatan	Jml Kel.
1	32.73.15	BANDUNG KULON	8	1	3273010	BANDUNG KULON	8
2	32.73.03	BABAKAN CI-PARAY	6	2	3273020	BABAKAN CI-PARAY	6
3	32.73.04	BOJONGLOA KALER	5	3	3273030	BOJONGLOA KALER	5
4	32.73.17	BOJONGLOA KIDUL	6	4	3273040	BOJONGLOA KIDUL	6
5	32.73.10	ASTANA ANYAR	6	5	3273050	ASTANA ANYAR	6
6	32.73.11	REGOL	7	6	3273060	REGOL	7
7	32.73.13	LENGKONG	7	7	3273070	LENGKONG	7
8	32.73.21	BANDUNG KIDUL	4	8	3273080	BANDUNG KIDUL	4
9	32.73.22	BUAHBATU	4	9	3273090	BUAHBATU	4
10	32.73.23	RANCASARI	4	10	3273100	RANCASARI	4
11	32.73.27	GEDEBAGE	4	11	3273101	GEDEBAGE	4
12	32.73.25	CIBIRU	4	12	3273110	CIBIRU	4
13	32.73.28	PANYILEUKAN	4	13	3273111	PANYILEUKAN	4
14	32.73.26	UJUNGBERUNG	5	14	3273120	UJUNG BERUNG	5
15	32.73.29	CINAMBO	4	15	3273121	CINAMBO	4
16	32.73.24	ARCAMANIK	4	16	3273130	ARCAMANIK	4
17	32.73.20	ANTAPANI	4	17	3273141	ANTAPANI	4
18	32.73.30	MANDALAJATI	4	18	3273142	MANDALAJATI	4
19	32.73.16	KIARACONDONG	6	19	3273150	KIARACONDONG	6

https://jabar.bps.go.id

JUMLAH DESA/KELURAHAN PER KECAMATAN

PROVINSI : [32] JAWA BARAT
KOTA : [73] BANDUNG

Data Kemendagri				MFD 2021 Semester 2			
No	Kode	Nama Kecamatan	Jml Kel.	No	Kode	Nama Kecamatan	Jml Kel.
20	32.73.12	BATUNUNGGAL	8	20	3273160	BATUNUNGGAL	8
21	32.73.19	SUMUR BANDUNG	4	21	3273170	SUMUR BANDUNG	4
22	32.73.05	ANDIR	6	22	3273180	ANDIR	6
23	32.73.06	CICENDO	6	23	3273190	CICENDO	6
24	32.73.09	BANDUNG WETAN	3	24	3273200	BANDUNG WETAN	3
25	32.73.14	CIBEUNYING KIDUL	6	25	3273210	CIBEUNYING KIDUL	6
26	32.73.18	CIBEUNYING KALER	4	26	3273220	CIBEUNYING KALER	4
27	32.73.02	COBLONG	6	27	3273230	COBLONG	6
28	32.73.07	SUKAJADI	5	28	3273240	SUKAJADI	5
29	32.73.01	SUKASARI	4	29	3273250	SUKASARI	4
30	32.73.08	CIDADAP	3	30	3273260	CIDADAP	3

https://jabar.bps.go.id

PROVINSI : [32] JAWA BARAT
KOTA : [73] BANDUNG
KECAMATAN : [010] BANDUNG KULON

Data Kemendagri			MFD 2021 Semester 2			
No	Kode	Nama Kelurahan	No	Kode	Nama Kelurahan	Status*
1	32.73.15.1006	GEMPOL SARI	1	3273010001	GEMPOL SARI	1
2	32.73.15.1005	CIGONDEWAH KALER	2	3273010002	CIGONDEWAH KALER	1
3	32.73.15.1008	CIGONDEWAH KIDUL	3	3273010003	CIGONDEWAH KIDUL	1
4	32.73.15.1007	CIGONDEWAH RAHAYU	4	3273010004	CIGONDEWAH RAHAYU	1
5	32.73.15.1004	CARINGIN	5	3273010005	CARINGIN	1
6	32.73.15.1003	WARUNG MUNCANG	6	3273010006	WARUNG MUNCANG	1
7	32.73.15.1002	CIBUNTU	7	3273010007	CIBUNTU	1
8	32.73.15.1001	CIJERAH	8	3273010008	CIJERAH	1

https://jabar.bps.go.id

Catatan :
*) 1. Perkotaan
2. Perdesaan

DAFTAR DESA/KELURAHAN

PROVINSI : [32] JAWA BARAT
KOTA : [73] BANDUNG
KECAMATAN : [020] BABAKAN CIPARAY

Data Kemendagri			MFD 2021 Semester 2			
No	Kode	Nama Kelurahan	No	Kode	Nama Kelurahan	Status*
1	32.73.03.1005	MARGASUKA	1	3273020001	MARGASUKA	1
2	32.73.03.1006	CIRANGRANG	2	3273020002	CIRANGRANG	1
3	32.73.03.1004	MARGAHAYU UTARA	3	3273020003	MARGAHAYU UTARA	1
4	32.73.03.1001	BABAKAN CIPARAY	4	3273020004	BABAKAN CIPARAY	1
5	32.73.03.1002	BABAKAN	5	3273020005	BABAKAN	1
6	32.73.03.1003	SUKAHAJI	6	3273020006	SUKAHAJI	1

Catatan :
*) 1. Perkotaan
2. Perdesaan

https://jabar.bps.go.id

PROVINSI : [32] JAWA BARAT
KOTA : [73] BANDUNG
KECAMATAN : [030] BOJONGLOA KALER

Data Kemendagri			MFD 2021 Semester 2			
No	Kode	Nama Kelurahan	No	Kode	Nama Kelurahan	Status*
1	32.73.04.1001	KOPO	1	3273030001	KOPO	1
2	32.73.04.1005	SUKA ASIH	2	3273030002	SUKA ASIH	1
3	32.73.04.1004	BABAKAN ASIH	3	3273030003	BABAKAN ASIH	1
4	32.73.04.1002	BABAKAN TAROGONG	4	3273030004	BABAKAN TAROGONG	1
5	32.73.04.1003	JAMIKA	5	3273030005	JAMIKA	1

Catatan :
*) 1. Perkotaan
2. Perdesaan

https://jabar.bps.go.id

DAFTAR DESA/KELURAHAN

PROVINSI : [32] JAWA BARAT
KOTA : [73] BANDUNG
KECAMATAN : [040] BOJONGLOA KIDUL

Data Kemendagri			MFD 2021 Semester 2			
No	Kode	Nama Kelurahan	No	Kode	Nama Kelurahan	Status*
1	32.73.17.1005	CIBADUYUT KIDUL	1	3273040001	CIBADUYUT KIDUL	1
2	32.73.17.1006	CIBADUYUT WETAN	2	3273040002	CIBADUYUT WETAN	1
3	32.73.17.1004	MEKAR WANGI	3	3273040003	MEKAR WANGI	1
4	32.73.17.1003	CIBADUYUT	4	3273040004	CIBADUYUT	1
5	32.73.17.1002	KEBON LEGA	5	3273040005	KEBON LEGA	1
6	32.73.17.1001	SITUSAEUR	6	3273040006	SITUSAEUR	1

Catatan :
*) 1. Perkotaan
2. Perdesaan

https://jabar.bps.go.id

PROVINSI : [32] JAWA BARAT
KOTA : [73] BANDUNG
KECAMATAN : [050] ASTANA ANYAR

Data Kemendagri			MFD 2021 Semester 2			
No	Kode	Nama Kelurahan	No	Kode	Nama Kelurahan	Status*
1	32.73.10.1001	KARASAK	1	3273050001	KARASAK	1
2	32.73.10.1006	PELINDUNG HEWAN	2	3273050002	PELINDUNG HEWAN	1
3	32.73.10.1002	NYENGSERET	3	3273050003	NYENGSERET	1
4	32.73.10.1004	PANJUNAN	4	3273050004	PANJUNAN	1
5	32.73.10.1005	CIBADAK	5	3273050005	CIBADAK	1
6	32.73.10.1003	KARANG ANYAR	6	3273050006	KARANG ANYAR	1

Catatan :
*) 1. Perkotaan
2. Perdesaan

https://jabar.bps.go.id

DAFTAR DESA/KELURAHAN

PROVINSI : [32] JAWA BARAT
KOTA : [73] BANDUNG
KECAMATAN : [060] REGOL

Data Kemendagri			MFD 2021 Semester 2			
No	Kode	Nama Kelurahan	No	Kode	Nama Kelurahan	Status*
1	32.73.11.1005	CISEUREUH	1	3273060001	CISEUREUH	1
2	32.73.11.1007	PASIRLUYU	2	3273060002	PASIRLUYU	1
3	32.73.11.1002	ANCOL	3	3273060003	ANCOL	1
4	32.73.11.1001	CIGERELENG	4	3273060004	CIGERELENG	1
5	32.73.11.1006	CIATEUL	5	3273060005	CIATEUL	1
6	32.73.11.1003	PUNGKUR	6	3273060006	PUNGKUR	1
7	32.73.11.1004	BALONG GEDE	7	3273060007	BALONG GEDE	1

Catatan :
*) 1. Perkotaan
2. Perdesaan

https://jabar.bps.go.id

PROVINSI : [32] JAWA BARAT
KOTA : [73] BANDUNG
KECAMATAN : [070] LENGKONG

Data Kemendagri			MFD 2021 Semester 2			
No	Kode	Nama Kelurahan	No	Kode	Nama Kelurahan	Status*
1	32.73.13.1001	CIJAGRA	1	3273070001	CIJAGRA	1
2	32.73.13.1005	TURANGGA	2	3273070002	TURANGGA	1
3	32.73.13.1002	LINGKAR SELATAN	3	3273070003	LINGKAR SELATAN	1
4	32.73.13.1006	MALABAR	4	3273070004	MALABAR	1
5	32.73.13.1003	BURANGRANG	5	3273070005	BURANGRANG	1
6	32.73.13.1007	CIKAWAO	6	3273070006	CIKAWAO	1
7	32.73.13.1004	PALEDANG	7	3273070007	PALEDANG	1

Catatan :
*) 1. Perkotaan
2. Perdesaan

https://jabar.bps.go.id

PROVINSI : [32] JAWA BARAT
KOTA : [73] BANDUNG
KECAMATAN : [080] BANDUNG KIDUL

Data Kemendagri			MFD 2021 Semester 2			
No	Kode	Nama Kelurahan	No	Kode	Nama Kelurahan	Status*
1	32.73.21.1002	WATES	1	3273080001	WATES	1
2	32.73.21.1003	MENGGER	2	3273080002	MENGGER	1
3	32.73.21.1001	BATUNUNG-GAL	3	3273080003	BATUNUNG-GAL	1
4	32.73.21.1004	KUJANGSARI	4	3273080004	KUJANGSARI	1

Catatan :
*) 1. Perkotaan
2. Perdesaan

https://jabar.bps.go.id

PROVINSI : [32] JAWA BARAT
KOTA : [73] BANDUNG
KECAMATAN : [090] BUAHBATU

Data Kemendagri			MFD 2021 Semester 2			
No	Kode	Nama Kelurahan	No	Kode	Nama Kelurahan	Status*
1	32.73.22.1003	CIJAURA	1	3273090001	CIJAURA	1
2	32.73.22.1002	MARGASARI	2	3273090002	MARGASARI	1
3	32.73.22.1001	SEKEJATI	3	3273090003	SEKEJATI	1
4	32.73.22.1004	JATISARI	4	3273090004	JATISARI	1

Catatan :
*) 1. Perkotaan
2. Perdesaan

PROVINSI : [32] JAWA BARAT
KOTA : [73] BANDUNG
KECAMATAN : [100] RANCASARI

Data Kemendagri			MFD 2021 Semester 2			
No	Kode	Nama Kelurahan	No	Kode	Nama Kelurahan	Status*
1	32.73.23.1002	DERWATI	1	3273100001	DERWATI	1
2	32.73.23.1001	CIPAMOKOLAN	2	3273100002	CIPAMOKOLAN	1
3	32.73.23.1003	MANJAHLEGA	3	3273100005	MANJAHLEGA	1
4	32.73.23.1004	MEKARMULYA	4	3273100006	MEKARMULYA	1

Catatan :
*) 1. Perkotaan
2. Perdesaan

http://jabar.bps.go.id

PROVINSI : [32] JAWA BARAT
KOTA : [73] BANDUNG
KECAMATAN : [101] GEDEBAGE

Data Kemendagri			MFD 2021 Semester 2			
No	Kode	Nama Kelurahan	No	Kode	Nama Kelurahan	Status*
1	32.73.27.1003	RANCABO LANG	1	3273101001	RANCABO LANG	1
2	32.73.27.1004	RANCA NUMPANG	2	3273101002	RANCA NUMPANG	1
3	32.73.27.1002	CISARANTEN KIDUL	3	3273101003	CISARANTEN KIDUL	1
4	32.73.27.1001	CIMINCRANG	4	3273101004	CIMINCRANG	1

Catatan :
*) 1. Perkotaan
2. Perdesaan

PROVINSI : [32] JAWA BARAT
KOTA : [73] BANDUNG
KECAMATAN : [110] CIBIRU

Data Kemendagri			MFD 2021 Semester 2			
No	Kode	Nama Kelurahan	No	Kode	Nama Kelurahan	Status*
1	32.73.25.1003	PASIR BIRU	1	3273110003	PASIR BIRU	1
2	32.73.25.1002	CIPADUNG	2	3273110004	CIPADUNG	1
3	32.73.25.1001	PALASARI	3	3273110005	PALASARI	1
4	32.73.25.1004	CISURUPAN	4	3273110006	CISURUPAN	1

Catatan :
*) 1. Perkotaan
2. Perdesaan

https://jabar.bps.go.id

PROVINSI : [32] JAWA BARAT
KOTA : [73] BANDUNG
KECAMATAN : [111] PANYILEUKAN

Data Kemendagri			MFD 2021 Semester 2			
No	Kode	Nama Kelurahan	No	Kode	Nama Kelurahan	Status*
1	32.73.28.1004	MEKARMULYA	1	3273111001	MEKARMULYA	1
2	32.73.28.1002	CIPADUNG KIDUL	2	3273111002	CIPADUNG KIDUL	1
3	32.73.28.1003	CIPADUNG WETAN	3	3273111003	CIPADUNG WETAN	1
4	32.73.28.1001	CIPADUNG KULON	4	3273111004	CIPADUNG KULON	1

Catatan :
*) 1. Perkotaan
2. Perdesaan

PROVINSI : [32] JAWA BARAT
KOTA : [73] BANDUNG
KECAMATAN : [120] UJUNG BERUNG

Data Kemendagri			MFD 2021 Semester 2			
No	Kode	Nama Kelurahan	No	Kode	Nama Kelurahan	Status*
1	32.73.26.1007	PASANGGRA-HAN	1	3273120003	PASANGGRA-HAN	1
2	32.73.26.1006	PASIRJATI	2	3273120004	PASIRJATI	1
3	32.73.26.1005	PASIR WANGI	3	3273120005	PASIR WANGI	1
4	32.73.26.1004	CIGENDING	4	3273120006	CIGENDING	1
5	32.73.26.1003	PASIR ENDAH	5	3273120007	PASIR ENDAH	1

Catatan :
*) 1. Perkotaan
2. Perdesaan

https://jabar.bps.go.id

PROVINSI : [32] JAWA BARAT
KOTA : [73] BANDUNG
KECAMATAN : [121] CINAMBO

Data Kemendagri			MFD 2021 Semester 2			
No	Kode	Nama Kelurahan	No	Kode	Nama Kelurahan	Status*
1	32.73.29.1001	CISARANTEN WETAN	1	3273121001	CISARANTEN WETAN	1
2	32.73.29.1004	BABAKAN PENGHULU	2	3273121002	BABAKAN PENGHULU	1
3	32.73.29.1002	PAKEMITAN	3	3273121003	PAKEMITAN	1
4	32.73.29.1003	SUKAMULYA	4	3273121004	SUKAMULYA	1

Catatan :
*) 1. Perkotaan
2. Perdesaan

DAFTAR DESA/KELURAHAN

PROVINSI : [32] JAWA BARAT
KOTA : [73] BANDUNG
KECAMATAN : [130] ARCAMANIK

Data Kemendagri			MFD 2021 Semester 2			
No	Kode	Nama Kelurahan	No	Kode	Nama Kelurahan	Status*
1	32.73.24.1003	CISARANTEN KULON	1	3273130001	CISARANTEN KULON	1
2	32.73.24.1002	CISARANTEN BINA HARA-PAN	2	3273130002	CISARANTEN BINA HARA-PAN	1
3	32.73.24.1001	SUKAMISKIN	3	3273130003	SUKAMISKIN	1
4	32.73.27.1002	CISARANTEN ENDAH	4	3273130005	CISARANTEN ENDAH	1

Catatan :
*) 1. Perkotaan
2. Perdesaan

https://jabar.bps.go.id

PROVINSI : [32] JAWA BARAT
KOTA : [73] BANDUNG
KECAMATAN : [141] ANTAPANI

Data Kemendagri			MFD 2021 Semester 2			
No	Kode	Nama Kelurahan	No	Kode	Nama Kelurahan	Status*
1	32.73.20.1005	ANTAPANI KIDUL	1	3273141001	ANTAPANI KIDUL	1
2	32.73.20.1004	ANTAPANI TENGAH	2	3273141002	ANTAPANI TENGAH	1
3	32.73.20.1006	ANTAPANI WETAN	3	3273141003	ANTAPANI WETAN	1
4	32.73.20.1001	ANTAPANI KULON	4	3273141004	ANTAPANI KULON	1

Catatan :
*) 1. Perkotaan
2. Perdesaan

https://jabar.bps.go.id

DAFTAR DESA/KELURAHAN

PROVINSI : [32] JAWA BARAT
KOTA : [73] BANDUNG
KECAMATAN : [142] MANDALAJATI

Data Kemendagri			MFD 2021 Semester 2			
No	Kode	Nama Kelurahan	No	Kode	Nama Kelurahan	Status*
1	32.73.30.1001	JATIHANDAP	1	3273142001	JATIHANDAP	1
2	32.73.30.1002	KARANG PAMULANG	2	3273142002	KARANG PAMULANG	1
3	32.73.30.1004	SINDANG JAYA	3	3273142003	SINDANG JAYA	1
4	32.73.30.1003	PASIR IMPUN	4	3273142004	PASIR IMPUN	1

Catatan :
*) 1. Perkotaan
2. Perdesaan

https://jabar.bps.go.id

PROVINSI : [32] JAWA BARAT
KOTA : [73] BANDUNG
KECAMATAN : [150] KIARACONDONG

Data Kemendagri			MFD 2021 Semester 2			
No	Kode	Nama Kelurahan	No	Kode	Nama Kelurahan	Status*
1	32.73.16.1006	KEBON KANGKUNG	1	3273150001	KEBON KANGKUNG	1
2	32.73.16.1001	SUKAPURA	2	3273150002	SUKAPURA	1
3	32.73.16.1002	KEBON JAYAN-TI	3	3273150003	KEBON JAYAN-TI	1
4	32.73.16.1005	BABAKANSARI	4	3273150004	BABAKANSARI	1
5	32.73.16.1003	BABAKAN SURABAYA	5	3273150005	BABAKAN SURABAYA	1
6	32.73.16.1004	CICAHEUM	6	3273150006	CICAHEUM	1

Catatan :
*) 1. Perkotaan
2. Perdesaan

https://jabar.bps.go.id

DAFTAR DESA/KELURAHAN

PROVINSI : [32] JAWA BARAT
KOTA : [73] BANDUNG
KECAMATAN : [160] BATUNUNGGAL

Data Kemendagri			MFD 2021 Semester 2			
No	Kode	Nama Kelurahan	No	Kode	Nama Kelurahan	Status*
1	32.73.12.1001	GUMURUH	1	3273160001	GUMURUH	1
2	32.73.12.1008	BINONG	2	3273160002	BINONG	1
3	32.73.12.1006	KEBON GEDANG	3	3273160003	KEBON GEDANG	1
4	32.73.12.1002	MALEER	4	3273160004	MALEER	1
5	32.73.12.1003	CIBANGKONG	5	3273160005	CIBANGKONG	1
6	32.73.12.1007	SAMOJA	6	3273160006	SAMOJA	1
7	32.73.12.1004	KACAPIRING	7	3273160007	KACAPIRING	1
8	32.73.12.1005	KEBON WARU	8	3273160008	KEBON WARU	1

Catatan :
*) 1. Perkotaan
2. Perdesaan

https://jabar.bps.go.id

PROVINSI : [32] JAWA BARAT
KOTA : [73] BANDUNG
KECAMATAN : [170] SUMUR BANDUNG

Data Kemendagri			MFD 2021 Semester 2			
No	Kode	Nama Kelurahan	No	Kode	Nama Kelurahan	Status*
1	32.73.19.1001	BRAGA	1	3273170001	BRAGA	1
2	32.73.19.1003	KEBON PISANG	2	3273170002	KEBON PISANG	1
3	32.73.19.1002	MERDEKA	3	3273170003	MERDEKA	1
4	32.73.19.1004	BABAKAN CIAMIS	4	3273170004	BABAKAN CIAMIS	1

Catatan :
*) 1. Perkotaan
2. Perdesaan

https://jabar.bps.go.id

DAFTAR DESA/KELURAHAN

PROVINSI : [32] JAWA BARAT
KOTA : [73] BANDUNG
KECAMATAN : [180] ANDIR

Data Kemendagri			MFD 2021 Semester 2			
No	Kode	Nama Kelurahan	No	Kode	Nama Kelurahan	Status*
1	32.73.05.1006	CAMPAKA	1	3273180001	CAMPAKA	1
2	32.73.05.1001	MALEBER	2	3273180002	MALEBER	1
3	32.73.05.1005	GARUDA	3	3273180003	GARUDA	1
4	32.73.05.1002	DUNGUS CARIANG	4	3273180004	DUNGUS CARIANG	1
5	32.73.05.1003	CIROYOM	5	3273180005	CIROYOM	1
6	32.73.05.1004	KEBON JERUK	6	3273180006	KEBON JERUK	1

Catatan :
*) 1. Perkotaan
2. Perdesaan

https://jabar.bps.go.id

PROVINSI : [32] JAWA BARAT
KOTA : [73] BANDUNG
KECAMATAN : [190] CICENDO

Data Kemendagri			MFD 2021 Semester 2			
No	Kode	Nama Kelurahan	No	Kode	Nama Kelurahan	Status*
1	32.73.06.1002	ARJUNA	1	3273190001	ARJUNA	1
2	32.73.06.1004	PASIRKALIKI	2	3273190002	PASIRKALIKI	1
3	32.73.06.1005	PAMAYONAN	3	3273190003	PAMAYONAN	1
4	32.73.06.1003	PAJAJARAN	4	3273190004	PAJAJARAN	1
5	32.73.06.1001	HUSEN SAS-TRANEGARA	5	3273190005	HUSEN SAS-TRANEGARA	1
6	32.73.06.1006	SUKARAJA	6	3273190006	SUKARAJA	1

Catatan :
*) 1. Perkotaan
2. Perdesaan

https://jabar.bps.go.id

PROVINSI : [32] JAWA BARAT
KOTA : [73] BANDUNG
KECAMATAN : [200] BANDUNG WETAN

Data Kemendagri			MFD 2021 Semester 2			
No	Kode	Nama Kelurahan	No	Kode	Nama Kelurahan	Status*
1	32.73.09.1002	TAMAN SARI	1	3273120001	TAMAN SARI	1
2	32.73.09.1003	CITARUM	2	3273120002	CITARUM	1
3	32.73.09.1001	CIHAPIT	3	3273120003	CIHAPIT	1

Catatan :
*) 1. Perkotaan
2. Perdesaan

PROVINSI : [32] JAWA BARAT
KOTA : [73] BANDUNG
KECAMATAN : [210] CIBEUNYING KIDUL

Data Kemendagri			MFD 2021 Semester 2			
No	Kode	Nama Kelurahan	No	Kode	Nama Kelurahan	Status*
1	32.73.14.1004	SUKAMAJU	1	3273210001	SUKAMAJU	1
2	32.73.14.1003	CICADAS	2	3273210002	CICADAS	1
3	32.73.14.1002	CIKUTRA	3	3273210003	CIKUTRA	1
4	32.73.14.1001	PADASUKA	4	3273210004	PADASUKA	1
5	32.73.14.1006	PASIRLAYUNG	5	3273210005	PASIRLAYUNG	1
6	32.73.14.1005	SUKAPADA	6	3273210006	SUKAPADA	1

Catatan :
*) 1. Perkotaan
2. Perdesaan

https://jabar.bps.go.id

PROVINSI : [32] JAWA BARAT
KOTA : [73] BANDUNG
KECAMATAN : [220] CIBEUNYING KALER

Data Kemendagri			MFD 2021 Semester 2			
No	Kode	Nama Kelurahan	No	Kode	Nama Kelurahan	Status*
1	32.73.18.1001	CIHAURGEULIS	1	3273220001	CIHAURGEULIS	1
2	32.73.18.1002	SUKALUYU	2	3273220002	SUKALUYU	1
3	32.73.18.1003	NEGLASARI	3	3273220003	NEGLASARI	1
4	32.73.18.1004	CIGADUNG	4	3273220004	CIGADUNG	1

Catatan :
*) 1. Perkotaan
2. Perdesaan

https://jabar.bps.go.id

PROVINSI : [32] JAWA BARAT
KOTA : [73] BANDUNG
KECAMATAN : [230] COBLONG

Data Kemendagri			MFD 2021 Semester 2			
No	Kode	Nama Kelurahan	No	Kode	Nama Kelurahan	Status*
1	32.73.02.1001	CIPAGANTI	1	3273230001	CIPAGANTI	1
2	32.73.02.1006	LEBAK SILI-WANGI	2	3273230002	LEBAK SILI-WANGI	1
3	32.73.02.1002	LEBAK GEDE	3	3273230003	LEBAK GEDE	1
4	32.73.02.1003	SADANG SERANG	4	3273230004	SADANG SERANG	1
5	32.73.02.1005	SEKELOA	5	3273230005	SEKELOA	1
6	32.73.02.1004	DAGO	6	3273230006	DAGO	1

Catatan :
*) 1. Perkotaan
2. Perdesaan

PROVINSI : [32] JAWA BARAT
KOTA : [73] BANDUNG
KECAMATAN : [240] SUKAJADI

Data Kemendagri			MFD 2021 Semester 2			
No	Kode	Nama Kelurahan	No	Kode	Nama Kelurahan	Status*
1	32.73.07.1003	SUKAWARNA	1	3273240001	SUKAWARNA	1
2	32.73.07.1004	SUKAGALIH	2	3273240002	SUKAGALIH	1
3	32.73.07.1005	SUKABUNGAH	3	3273240003	SUKABUNGAH	1
4	32.73.07.1002	CIPEDES	4	3273240004	CIPEDES	1
5	32.73.07.1001	PASTEUR	5	3273240005	PASTEUR	1

Catatan :
*) 1. Perkotaan
2. Perdesaan

https://jabar.bps.go.id

PROVINSI : [32] JAWA BARAT
KOTA : [73] BANDUNG
KECAMATAN : [250] SUKASARI

Data Kemendagri			MFD 2021 Semester 2			
No	Kode	Nama Kelurahan	No	Kode	Nama Kelurahan	Status*
1	32.73.01.1004	SARIJADI	1	3273250001	SARIJADI	1
2	32.73.01.1001	SUKARASA	2	3273250002	SUKARASA	1
3	32.73.01.1002	GEGERKA-LONG	3	3273250003	GEGERKA-LONG	1
4	32.73.01.1003	ISOLA	4	3273250004	ISOLA	1

Catatan :
*) 1. Perkotaan
2. Perdesaan

PROVINSI : [32] JAWA BARAT
KOTA : [73] BANDUNG
KECAMATAN : [260] CIDADAP

Data Kemendagri			MFD 2021 Semester 2			
No	Kode	Nama Kelurahan	No	Kode	Nama Kelurahan	Status*
1	32.73.08.1001	HEGARMANAH	1	3273260001	HEGARMANAH	1
2	32.73.08.1002	CIUMBULEUIT	2	3273260002	CIUMBULEUIT	1
3	32.73.08.1003	LEDENG	3	3273260003	LEDENG	1

Catatan :
*) 1. Perkotaan
2. Perdesaan

https://jabar.bps.go.id

https://jabar.bps.go.id

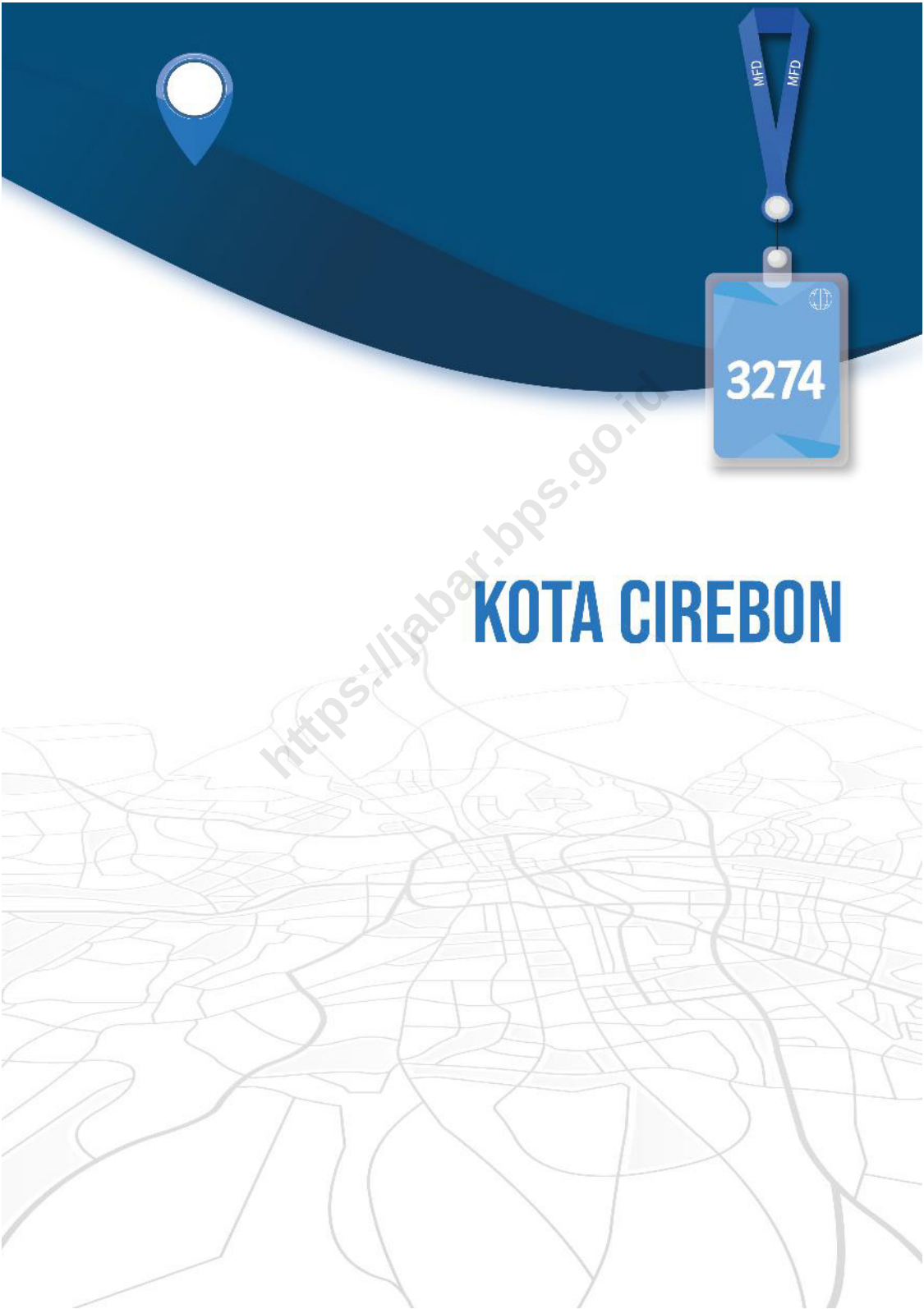

https://jabar.bps.go.id

https://jabar.bps.go.id

PROVINSI : [32] JAWA BARAT
KOTA : [74] CIREBON

Data Kemendagri			MFD 2021 Semester 2		
No	Kode	Nama Kecamatan	No	Kode	Nama Kecamatan
1	32.74.03	HARJAMUKTI	1	3274010	HARJAMUKTI
2	32.74.02	LEMAH WUNGKUK	2	3274020	LEMAH WUNGKUK
3	32.74.04	PEKALIPAN	3	3274030	PEKALIPAN
4	32.74.05	KESAMBI	4	3274040	KESAMBI
5	32.74.01	KEJAKSAN	5	3274050	KEJAKSAN

https://jabar.bps.go.id

JUMLAH DESA/KELURAHAN PER KECAMATAN

PROVINSI : **[32] JAWA BARAT**
KOTA : **[74] CIREBON**

Data Kemendagri				MFD 2021 Semester 2			
No	Kode	Nama Kecamatan	Jml Kel.	No	Kode	Nama Kecamatan	Jml Kel.
1	32.74.03	HARJAMUKTI	5	1	3274010	HARJAMUKTI	5
2	32.74.02	LEMAH WUNGKUK	4	2	3274020	LEMAHWUNGKUK	4
3	32.74.04	PEKALIPAN	4	3	3274030	PEKALIPAN	4
4	32.74.05	KESAMBI	5	4	3274040	KESAMBI	5
5	32.74.01	KEJAKSAN	4	5	3274050	KEJAKSAN	4

https://jabar.bps.go.id

PROVINSI : [32] JAWA BARAT
KOTA : [74] CIREBON
KECAMATAN : [010] HARJAMUKTI

Data Kemendagri			MFD 2021 Semester 2			
No	Kode	Nama Kelurahan	No	Kode	Nama Kelurahan	Status*
1	32.74.03.1005	ARGASUNYA	1	3274010001	ARGASUNYA	1
2	32.74.03.1001	KALIJAGA	2	3274010002	KALIJAGA	1
3	32.74.03.1002	HARJAMUKTI	3	3274010003	HARJAMUKTI	1
4	32.74.03.1003	KECAPI	4	3274010004	KECAPI	1
5	32.74.03.1004	LARANGAN	5	3274010005	LARANGAN	1

Catatan :
*) 1. Perkotaan
2. Perdesaan

https://jabar.bps.go.id

DAFTAR DESA/KELURAHAN

PROVINSI : [32] JAWA BARAT
KOTA : [74] CIREBON
KECAMATAN : [020] LEMAH WUNGKUK

Data Kemendagri			MFD 2021 Semester 2			
No	Kode	Nama Kelurahan	No	Kode	Nama Kelurahan	Status*
1	32.74.02.1001	PEGAMBIRAN	1	3274020001	PEGAMBIRAN	1
2	32.74.02.1003	KESEPUHAN	2	3274020002	KESEPUHAN	1
3	32.74.02.1002	LEMAH-WUNGKUK	3	3274020003	LEMAH-WUNGKUK	1
4	32.74.02.1004	PANUNJAN	4	3274020004	PANUNJAN	1

Catatan :
*) 1. Perkotaan
2. Perdesaan

https://jabar.bps.go.id

PROVINSI : [32] JAWA BARAT
KOTA : [74] CIREBON
KECAMATAN : [030] PEKALIPAN

Data Kemendagri			MFD 2021 Semester 2			
No	Kode	Nama Kelurahan	No	Kode	Nama Kelurahan	Status*
1	32.74.04.1001	JAGASATRU	1	3274030001	JAGASATRU	1
2	32.74.04.1003	PULASAREN	2	3274030002	PULASAREN	1
3	32.74.04.1002	PEKALIPAN	3	3274030003	PEKALIPAN	1
4	32.74.04.1004	PEKALANGAN	4	3274030004	PEKALANGAN	1

Catatan :
*) 1. Perkotaan
2. Perdesaan

https://jabar.bps.go.id

DAFTAR DESA/KELURAHAN

PROVINSI : [32] JAWA BARAT
KOTA : [74] CIREBON
KECAMATAN : [040] KESAMBI

Data Kemendagri			MFD 2021 Semester 2			
No	Kode	Nama Kelurahan	No	Kode	Nama Kelurahan	Status*
1	32.74.05.1005	KARYAMULYA	1	3274040001	KARYAMULYA	1
2	32.74.05.1002	SUNYARAGI	2	3274040002	SUNYARAGI	1
3	32.74.05.1004	DRAJAT	3	3274040003	DRAJAT	1
4	32.74.05.1003	KESAMBI	4	3274040004	KESAMBI	1
5	32.74.05.1001	PEKIRINGAN	5	3274040005	PEKIRINGAN	1

Catatan :
*) 1. Perkotaan
2. Perdesaan

https://jabar.bps.go.id

PROVINSI : [32] JAWA BARAT
KOTA : [74] CIREBON
KECAMATAN : [050] KEJAKSAN

Data Kemendagri			MFD 2021 Semester 2			
No	Kode	Nama Kelurahan	No	Kode	Nama Kelurahan	Status*
1	32.74.01.1001	KEJAKSAN	1	3274050001	KEJAKSAN	1
2	32.74.01.1004	KEBONBARU	2	3274050002	KEBONBARU	1
3	32.74.01.1002	SUKAPURA	3	3274050003	SUKAPURA	1
4	32.74.01.1003	KESENDEN	4	3274050004	KESENDEN	1

Catatan :
*) 1. Perkotaan
2. Perdesaan

https://jabar.bps.go.id

https://jabar.bps.go.id

KOTA BEKASI

https://jabar.bps.go.id

https://jabar.bps.go.id

PROVINSI : [32] JAWA BARAT
KOTA : [75] BEKASI

Data Kemendagri			MFD 2021 Semester 2		
No	Kode	Nama Kecamatan	No	Kode	Nama Kecamatan
1	32.75.08	PONDOKGEDE	1	3275010	PONDOKGEDE
2	32.75.10	JATISAMPURNA	2	3275011	JATISAMPURNA
3	32.75.12	PONDOKMELATI	3	3275012	PONDOKMELATI
4	32.75.09	JATIASIH	4	3275020	JATIASIH
5	32.75.07	BANTARGEBANG	5	3275030	BANTARGEBANG
6	32.75.11	MUSTIKAJAYA	6	3275031	MUSTIKAJAYA
7	32.75.01	BEKASI TIMUR	7	3275040	BEKASI TIMUR
8	32.75.05	RAWALUMBU	8	3275041	RAWALUMBU
9	32.75.04	BEKASI SELATAN	9	3275050	BEKASI SELATAN
10	32.75.02	BEKASI BARAT	10	3275060	BEKASI BARAT
11	32.75.06	MEDANSATRIA	11	3275061	MEDANSATRIA
12	32.75.03	BEKASI UTARA	12	3275070	BEKASI UTARA

https://jabar.bps.go.id

JUMLAH DESA/KELURAHAN PER KECAMATAN

PROVINSI : [32] JAWA BARAT
KOTA : [75] BEKASI

Data Kemendagri				MFD 2021 Semester 2			
No	Kode	Nama Kecamatan	Jml Kel.	No	Kode	Nama Kecamatan	Jml Kel.
1	32.75.08	PONDOKGEDE	5	1	3275010	PONDOK GEDE	5
2	32.75.10	JATISAMPURNA	5	2	3275011	JATI SAMPURNA	5
3	32.75.12	PONDOKMELATI	4	3	3275012	PONDOK MELATI	4
4	32.75.09	JATIASIH	6	4	3275020	JATIASIH	6
5	32.75.07	BANTARGEBANG	4	5	3275030	BANTARGEBANG	4
6	32.75.11	MUSTIKAJAYA	4	6	3275031	MUSTIKA JAYA	4
7	32.75.01	BEKASI TIMUR	4	7	3275040	BEKASI TIMUR	4
8	32.75.05	RAWALUMBU	4	8	3275041	RAWALUMBU	4
9	32.75.04	BEKASI SELATAN	5	9	3275050	BEKASI SELATAN	5
10	32.75.02	BEKASI BARAT	5	10	3275060	BEKASI BARAT	5
11	32.75.06	MEDANSATRIA	4	11	3275061	MEDANSATRIA	4
12	32.75.03	BEKASI UTARA	6	12	3275070	BEKASI UTARA	6

https://jabar.bps.go.id

PROVINSI : [32] JAWA BARAT
KOTA : [75] BEKASI
KECAMATAN : [010] PONDOKGEDE

Data Kemendagri			MFD 2021 Semester 2			
No	Kode	Nama Kelurahan	No	Kode	Nama Kelurahan	Status*
1	32.75.08.1003	JATIMAKMUR	1	3275010008	JATIMAKMUR	1
2	32.75.08.1001	JATIWARINGIN	2	3275010009	JATIWARINGIN	1
3	32.75.08.1002	JATIBENING	3	3275010010	JATIBENING	1
4	32.75.08.1007	JATICEMPAKA	4	3275010011	JATICEMPAKA	1
5	32.75.08.1006	JATIBENING BARU	5	3275010012	JATIBENING BARU	1

Catatan :
*) 1. Perkotaan
2. Perdesaan

https://jabar.bps.go.id

PROVINSI : [32] JAWA BARAT
KOTA : [75] BEKASI
KECAMATAN : [011] JATISAMPURNA

Data Kemendagri			MFD 2021 Semester 2			
No	Kode	Nama Kelurahan	No	Kode	Nama Kelurahan	Status*
1	32.75.10.1002	JATIKARYA	1	3275011001	JATIKARYA	1
2	32.75.10.1001	JATISAMPUR-NA	2	3275011002	JATISAMPUR-NA	1
3	32.75.10.1004	JATIRANGGA	3	3275011003	JATIRANGGA	1
4	32.75.10.1003	JATIRANGGON	4	3275011004	JATIRANGGON	1
5	32.75.10.1005	JATIRADEN	5	3275011006	JATIRADEN	1

Catatan :
*) 1. Perkotaan
2. Perdesaan

https://jabar.bps.go.id

PROVINSI : [32] JAWA BARAT
KOTA : [75] BEKASI
KECAMATAN : [012] PONDOKMELATI

Data Kemendagri			MFD 2021 Semester 2			
No	Kode	Nama Kelurahan	No	Kode	Nama Kelurahan	Status*
1	32.75.12.1004	JATIMURNI	1	3275012001	JATIMURNI	1
2	32.75.12.1003	JATIMELATI	2	3275012002	JATIMELATI	1
3	32.75.12.1002	JATIWARNA	3	3275012003	JATIWARNA	1
4	32.75.12.1001	JATIRAHAYU	4	3275012004	JATIRAHAYU	1

Catatan :
*) 1. Perkotaan
2. Perdesaan

PROVINSI : [32] JAWA BARAT
KOTA : [75] BEKASI
KECAMATAN : [020] JATIASIH

Data Kemendagri			MFD 2021 Semester 2			
No	Kode	Nama Kelurahan	No	Kode	Nama Kelurahan	Status*
1	32.75.09.1006	JATISARI	1	3275020001	JATISARI	1
2	32.75.09.1005	JATILUHUR	2	3275020002	JATILUHUR	1
3	32.75.09.1004	JATIRASA	3	3275020003	JATIRASA	1
4	32.75.09.1002	JATIASIH	4	3275020004	JATIASIH	1
5	32.75.09.1001	JATIMEKAR	5	3275020005	JATIMEKAR	1
6	32.75.09.1003	JATIKRAMAT	6	3275020006	JATIKRAMAT	1

Catatan :
*) 1. Perkotaan
2. Perdesaan

https://jabar.bps.go.id

PROVINSI : [32] JAWA BARAT
KOTA : [75] BEKASI
KECAMATAN : [030] BANTARGEBANG

Data Kemendagri			MFD 2021 Semester 2			
No	Kode	Nama Kelurahan	No	Kode	Nama Kelurahan	Status*
1	32.75.07.1007	CIKETINGUDIK	1	3275030001	CIKETINGUDIK	1
2	32.75.07.1008	SUMUR BATU	2	3275030002	SUMUR BATU	1
3	32.75.07.1004	CIKIWUL	3	3275030003	CIKIWUL	1
4	32.75.07.1003	BANTARGE-BANG	4	3275030004	BANTARGE-BANG	1

Catatan :
*) 1. Perkotaan
2. Perdesaan

PROVINSI : [32] JAWA BARAT
KOTA : [75] BEKASI
KECAMATAN : [031] MUSTIKAJAYA

Data Kemendagri			MFD 2021 Semester 2			
No	Kode	Nama Kelurahan	No	Kode	Nama Kelurahan	Status*
1	32.75.11.1001	PADURENAN	1	3275031001	PADURENAN	1
2	32.75.11.1002	CIMUNING	2	3275031002	CIMUNING	1
3	32.75.11.1003	MUSTIKAJAYA	3	3275031003	MUSTIKA JAYA	1
4	32.75.11.1004	MUSTIKASARI	4	3275031004	MUSTIKA SARI	1

Catatan :
*) 1. Perkotaan
2. Perdesaan

http://jabar.bps.go.id

PROVINSI : [32] JAWA BARAT
KOTA : [75] BEKASI
KECAMATAN : [040] BEKASI TIMUR

Data Kemendagri			MFD 2021 Semester 2			
No	Kode	Nama Kelurahan	No	Kode	Nama Kelurahan	Status*
1	32.75.01.1002	MARGAHAYU	1	3275040005	MARGAHAYU	1
2	32.75.01.1001	BEKASI JAYA	2	3275040006	BEKASI JAYA	1
3	32.75.01.1003	DUREN JAYA	3	3275040007	DUREN JAYA	1
4	32.75.01.1004	AREN JAYA	4	3275040008	AREN JAYA	1

Catatan :
*) 1. Perkotaan
2. Perdesaan

PROVINSI : [32] JAWA BARAT
KOTA : [75] BEKASI
KECAMATAN : [041] RAWALUMBU

Data Kemendagri			MFD 2021 Semester 2			
No	Kode	Nama Kelurahan	No	Kode	Nama Kelurahan	Status*
1	32.75.05.1004	BOJONG MEN-TENG	1	3275041001	BOJONG MEN-TENG	1
2	32.75.05.1001	BOJONG RAWALUMBU	2	3275041002	BOJONG RAWALUMBU	1
3	32.75.05.1003	SEPANJANG-JAYA	3	3275041003	SEPANJANG JAYA	1
4	32.75.05.1002	PENGASINAN	4	3275041004	PENGASINAN	1

Catatan :
*) 1. Perkotaan
2. Perdesaan

https://jabar.bps.go.id

PROVINSI : [32] JAWA BARAT
KOTA : [75] BEKASI
KECAMATAN : [050] BEKASI SELATAN

Data Kemendagri			MFD 2021 Semester 2			
No	Kode	Nama Kelurahan	No	Kode	Nama Kelurahan	Status*
1	32.75.04.1003	JAKA MULYA	1	3275050001	JAKA MULYA	1
2	32.75.04.1004	JAKA SETIA	2	3275050002	JAKA SETIA	1
3	32.75.04.1001	PEKAYON JAYA	3	3275050003	PEKAYON JAYA	1
4	32.75.04.1002	MARGA JAYA	4	3275050004	MARGA JAYA	1
5	32.75.04.1005	KAYURINGIN JAYA	5	3275050007	KAYURINGIN JAYA	1

Catatan :
*) 1. Perkotaan
2. Perdesaan

PROVINSI : [32] JAWA BARAT
KOTA : [75] BEKASI
KECAMATAN : [060] BEKASI BARAT

Data Kemendagri			MFD 2021 Semester 2			
No	Kode	Nama Kelurahan	No	Kode	Nama Kelurahan	Status*
1	32.75.02.1004	BINTARAJAYA	1	3275060001	BINTARA JAYA	1
2	32.75.02.1001	BINTARA	2	3275060002	BINTARA	1
3	32.75.02.1002	KRANJI	3	3275060003	KRANJI	1
4	32.75.02.1003	KOTA BARU	4	3275060005	KOTA BARU	1
5	32.75.02.1005	JAKA SAMPUR-NA	5	3275060008	JAKA SAMPUR-NA	1

Catatan :
*) 1. Perkotaan
2. Perdesaan

https://jabar.bps.go.id

PROVINSI : [32] JAWA BARAT
KOTA : [75] BEKASI
KECAMATAN : [061] MEDAN SATRIA

Data Kemendagri			MFD 2021 Semester 2			
No	Kode	Nama Kelurahan	No	Kode	Nama Kelurahan	Status*
1	32.75.06.1002	HARAPAN MULYA	1	3275061001	HARAPAN MULYA	1
2	32.75.06.1004	KALIBARU	2	3275061002	KALI BARU	1
3	32.75.06.1001	MEDANSATRIA	3	3275061003	MEDAN SATRIA	1
4	32.75.06.1003	PEJUANG	4	3275061004	PEJUANG	1

Catatan :
*) 1. Perkotaan
2. Perdesaan

PROVINSI : [32] JAWA BARAT
KOTA : [75] BEKASI
KECAMATAN : [070] BEKASI UTARA

Data Kemendagri			MFD 2021 Semester 2			
No	Kode	Nama Kelurahan	No	Kode	Nama Kelurahan	Status*
1	32.75.03.1006	HARAPANJAYA	1	3275070001	HARAPAN JAYA	1
2	32.75.03.1001	KALIABANG TENGAH	2	3275070002	KALIABANG TENGAH	1
3	32.75.03.1002	PERWIRA	3	3275070003	PERWIRA	1
4	32.75.03.1003	HARAPAN BARU	4	3275070004	HARAPAN BARU	1
5	32.75.03.1004	TELUK PU-CUNG	5	3275070005	TELUK PU-CUNG	1
6	32.75.03.1005	MARGAMULYA	6	3275070006	MARGA MULYA	1

Catatan :
*) 1. Perkotaan
2. Perdesaan

https://jabar.bps.go.id

https://jabar.bps.go.id

KOTA DEPOK

https://jabar.bps.go.id

https://jabar.bps.go.id

PROVINSI : [32] JAWA BARAT
KOTA : [76] DEPOK

Data Kemendagri			MFD 2021 Semester 2		
No	Kode	Nama Kecamatan	No	Kode	Nama Kecamatan
1	32.76.03	SAWANGAN	1	3276010	SAWANGAN
2	32.76.11	BOJONGSARI	2	3276011	BOJONGSARI
3	32.76.01	PANCORAN MAS	3	3276020	PANCORAN MAS
4	32.76.07	CIPAYUNG	4	3276021	CIPAYUNG
5	32.76.05	SUKMAJAYA	5	3276030	SUKMAJAYA
6	32.76.08	CILODONG	6	3276031	CILODONG
7	32.76.02	CIMANGGIS	7	3276040	CIMANGGIS
8	32.76.10	TAPOS	8	3276041	TAPOS
9	32.76.06	BEJI	9	3276050	BEJI
10	32.76.04	LIMO	10	3276060	LIMO
11	32.76.09	CINERE	11	3276061	CINERE

https://jabar.bps.go.id

JUMLAH DESA/KELURAHAN PER KECAMATAN

PROVINSI : [32] JAWA BARAT
KOTA : [76] DEPOK

Data Kemendagri				MFD 2021 Semester 2			
No	Kode	Nama Kecamatan	Jml Kel.	No	Kode	Nama Kecamatan	Jml Kel.
1	32.76.03	SAWANGAN	7	1	3276010	SAWANGAN	7
2	32.76.11	BOJONGSARI	7	2	3276011	BOJONGSARI	7
3	32.76.01	PANCORAN MAS	6	3	3276020	PANCORAN MAS	6
4	32.76.07	CIPAYUNG	5	4	3276021	CIPAYUNG	5
5	32.76.05	SUKMAJAYA	6	5	3276030	SUKMAJAYA	6
6	32.76.08	CILODONG	5	6	3276031	CILODONG	5
7	32.76.02	CIMANGGIS	6	7	3276040	CIMANGGIS	6
8	32.76.10	TAPOS	7	8	3276041	TAPOS	7
9	32.76.06	BEJI	6	9	3276050	BEJI	6
10	32.76.04	LIMO	4	10	3276060	LIMO	4
11	32.76.09	CINERE	4	11	3276061	CINERE	4

https://jabar.bps.go.id

PROVINSI : [32] JAWA BARAT
KOTA : [76] DEPOK
KECAMATAN : [010] SAWANGAN

Data Kemendagri			MFD 2021 Semester 2			
No	Kode	Nama Kelurahan	No	Kode	Nama Kelurahan	Status*
1	32.76.03.1003	PENGASINAN	1	3276010003	PENGASINAN	1
2	32.76.03.1002	BEDAHAN	2	3276010004	BEDAHAN	1
3	32.76.03.1001	PASIR PUTIH	3	3276010005	PASIR PUTIH	1
4	32.76.03.1011	SAWANGAN BARU	4	3276010006	SAWANGAN BARU	1
5	32.76.03.1010	SAWANGAN	5	3276010007	SAWANGAN	1
6	32.76.03.1012	KEDAUNG	6	3276010013	KEDAUNG	1
7	32.76.03.1009	CINANGKA	7	3276010017	CINANGKA	1

Catatan :
*) 1. Perkotaan
2. Perdesaan

https://jabar.bps.go.id

DAFTAR DESA/KELURAHAN

PROVINSI : [32] JAWA BARAT
KOTA : [76] DEPOK
KECAMATAN : [011] BOJONGSARI

Data Kemendagri			MFD 2021 Semester 2			
No	Kode	Nama Kelurahan	No	Kode	Nama Kelurahan	Status*
1	32.76.11.1007	DUREN SERIBU	1	3276110001	DUREN SERIBU	1
2	32.76.11.1006	DUREN MEKAR	2	3276110002	DUREN MEKAR	1
3	32.76.11.1001	BOJONGSARI	3	3276110003	BOJONGSARI	1
4	32.76.11.1002	BOJONGSARI BARU	4	3276110004	BOJONGSARI BARU	1
5	32.76.11.1005	CURUG	5	3276110005	CURUG	1
6	32.76.11.1004	PONDOK PETIR	6	3276110006	PONDOK PETIR	1
7	32.76.11.1003	SERUA	7	3276110007	SERUA	1

Catatan :
*) 1. Perkotaan
2. Perdesaan

https://jabar.bps.go.id

PROVINSI : [32] JAWA BARAT
KOTA : [76] DEPOK
KECAMATAN : [020] PANCORAN MAS

Data Kemendagri			MFD 2021 Semester 2			
No	Kode	Nama Kelurahan	No	Kode	Nama Kelurahan	Status*
1	32.76.01.1010	RANGKAPAN JAYA BARU	1	3276020006	RANGKAPAN JAYA BARU	1
2	32.76.01.1011	RANGKAPAN JAYA	2	3276020007	RANGKAPAN JAYA	1
3	32.76.01.1009	MAMPANG	3	3276020008	MAMPANG	1
4	32.76.01.1008	PANCORAN MAS	4	3276020009	PANCORAN MAS	1
5	32.76.01.1007	DEPOK JAYA	5	3276020010	DEPOK JAYA	1
6	32.76.01.1006	DEPOK	6	3276020011	DEPOK	1

Catatan :
*) 1. Perkotaan
2. Perdesaan

https://jabar.bps.go.id

DAFTAR DESA/KELURAHAN

PROVINSI : [32] JAWA BARAT
KOTA : [76] DEPOK
KECAMATAN : [021] CIPAYUNG

Data Kemendagri			MFD 2021 Semester 2			
No	Kode	Nama Kelurahan	No	Kode	Nama Kelurahan	Status*
1	32.76.07.1002	CIPAYUNG JAYA	1	3276021001	CIPAYUNG JAYA	1
2	32.76.07.1004	BOJONG PONDOK TERONG	2	3276021002	BOJONG PONDOK TERONG	1
3	32.76.07.1005	PONDOK JAYA	3	3276021003	PONDOK JAYA	1
4	32.76.07.1003	RATU JAYA	4	3276021004	RATU JAYA	1
5	32.76.07.1001	CIPAYUNG	5	3276021005	CIPAYUNG	1

Catatan :
*) 1. Perkotaan
2. Perdesaan

https://jabar.bps.go.id

PROVINSI : [32] JAWA BARAT
KOTA : [76] DEPOK
KECAMATAN : [030] SUKMAJAYA

Data Kemendagri			MFD 2021 Semester 2			
No	Kode	Nama Kelurahan	No	Kode	Nama Kelurahan	Status*
1	32.76.05.1001	SUKMAJAYA	1	3276030006	SUKMAJAYA	1
2	32.76.05.1010	TIRTAJAYA	2	3276030007	TIRTAJAYA	1
3	32.76.05.1004	MEKAR JAYA	3	3276030008	MEKAR JAYA	1
4	32.76.05.1003	ABADIJAYA	4	3276030009	ABADIJAYA	1
5	32.76.05.1005	BAKTI JAYA	5	3276030010	BAKTI JAYA	1
6	32.76.05.1008	CISALAK	6	3276030011	CISALAK	1

Catatan :
*) 1. Perkotaan
2. Perdesaan

https://jabar.bps.go.id

DAFTAR DESA/KELURAHAN

PROVINSI : [32] JAWA BARAT
KOTA : [76] DEPOK
KECAMATAN : [031] CILODONG

Data Kemendagri			MFD 2021 Semester 2			
No	Kode	Nama Kelurahan	No	Kode	Nama Kelurahan	Status*
1	32.76.08.1004	KALIMULYA	1	3276031001	KALIMULYA	1
2	32.76.08.1005	JATIMULYA	2	3276031002	JATIMULYA	1
3	32.76.08.1003	KALIBARU	3	3276031003	KALIBARU	1
4	32.76.08.1002	CILODONG	4	3276031004	CILODONG	1
5	32.76.08.1001	SUKAMAJU	5	3276031005	SUKAMAJU	1

Catatan :
*) 1. Perkotaan
2. Perdesaan

https://jabar.bps.go.id

PROVINSI : [32] JAWA BARAT
KOTA : [76] DEPOK
KECAMATAN : [040] CIMANGGIS

Data Kemendagri			MFD 2021 Semester 2			
No	Kode	Nama Kelurahan	No	Kode	Nama Kelurahan	Status*
1	32.76.02.1008	CURUG	1	3276040007	CURUG	1
2	32.76.02.1007	HARJAMUKTI	2	3276040009	HARJAMUKTI	1
3	32.76.02.1012	CISALAK PASAR	3	3276040010	CISALAK PASAR	1
4	32.76.02.1010	MEKARSARI	4	3276040011	MEKARSARI	1
5	32.76.02.1009	TUGU	5	3276040012	TUGU	1
6	32.76.02.1011	PASIR GUNUNG SELATAN	6	3276040013	PASIR GUNUNG SELATAN	1

Catatan :
*) 1. Perkotaan
2. Perdesaan

https://jabar.bps.go.id

DAFTAR DESA/KELURAHAN

PROVINSI : [32] JAWA BARAT
KOTA : [76] DEPOK
KECAMATAN : [041] TAPOS

Data Kemendagri			MFD 2021 Semester 2			
No	Kode	Nama Kelurahan	No	Kode	Nama Kelurahan	Status*
1	32.76.10.1006	CILANGKAP	1	3276041001	CILANGKAP	1
2	32.76.10.1007	CIMPAEUN	2	3276041002	CIMPAEUN	1
3	32.76.10.1001	TAPOS	3	3276041003	TAPOS	1
4	32.76.10.1002	LEUWI NANGUNG	4	3276041004	LEUWI NANGUNG	1
5	32.76.10.1005	JATIJAJAR	5	3276041005	JATIJAJAR	1
6	32.76.10.1004	SUKAMAJU BARU	6	3276041006	SUKAMAJU BARU	1
7	32.76.10.1003	SUKATANI	7	3276041007	SUKATANI	1

Catatan :
*) 1. Perkotaan
2. Perdesaan

https://jabar.bps.go.id

PROVINSI : [32] JAWA BARAT
KOTA : [76] DEPOK
KECAMATAN : [050] BEJI

Data Kemendagri			MFD 2021 Semester 2			
No	Kode	Nama Kelurahan	No	Kode	Nama Kelurahan	Status*
1	32.76.06.1001	BEJI	1	3276050001	BEJI	1
2	32.76.06.1006	BEJI TIMUR	2	3276050002	BEJI TIMUR	1
3	32.76.06.1004	KEMIRI MUKA	3	3276050003	KEMIRIMUKA	1
4	32.76.06.1005	PONDOK CINA	4	3276050004	PONDOK CINA	1
5	32.76.06.1002	KUKUSAN	5	3276050005	KUKUSAN	1
6	32.76.06.1003	TANAH BARU	6	3276050006	TANAH BARU	1

Catatan :
*) 1. Perkotaan
2. Perdesaan

https://jabar.bps.go.id

DAFTAR DESA/KELURAHAN

PROVINSI : [32] JAWA BARAT
KOTA : [76] DEPOK
KECAMATAN : [060] LIMO

Data Kemendagri			MFD 2021 Semester 2			
No	Kode	Nama Kelurahan	No	Kode	Nama Kelurahan	Status*
1	32.76.04.1001	MARUYUNG	1	3276060001	MERUYUNG	1
2	32.76.04.1002	GROGOL	2	3276060002	GROGOL	1
3	32.76.04.1003	KRUKUT	3	3276060003	KRUKUT	1
4	32.76.04.1004	LIMO	4	3276060004	LIMO	1

Catatan :
*) 1. Perkotaan
2. Perdesaan

https://jabar.bps.go.id

PROVINSI : [32] JAWA BARAT
KOTA : [76] DEPOK
KECAMATAN : [061] CINERE

Data Kemendagri			MFD 2021 Semester 2			
No	Kode	Nama Kelurahan	No	Kode	Nama Kelurahan	Status*
1	32.76.09.1001	CINERE	1	3276061001	CINERE	1
2	32.76.09.1002	GANDUL	2	3276061002	GANDUL	1
3	32.76.09.1004	PANGKALAN JATI BARU	3	3276061003	PANGKALAN-JATI BARU	1
4	32.76.09.1003	PANGKALAN JATI	4	3276061004	PANGKALAN-JATI	1

Catatan :
*) 1. Perkotaan
2. Perdesaan

https://jabar.bps.go.id

https://jabar.bps.go.id

KOTA CIMAHI

https://jabar.bps.go.id

https://jabar.bps.go.id

DAFTAR KECAMATAN

PROVINSI : [32] JAWA BARAT
KOTA : [77] CIMAHI

Data Kemendagri			MFD 2021 Semester 2		
No	Kode	Nama Kecamatan	No	Kode	Nama Kecamatan
1	32.77.01	CIMAHI SELATAN	1	3277010	CIMAHI SELATAN
2	32.77.02	CIMAHI TENGAH	2	3277020	CIMAHI TENGAH
3	32.77.03	CIMAHI UTARA	3	3277030	CIMAHI UTARA

https://jabar.bps.go.id

JUMLAH DESA/KELURAHAN PER KECAMATAN

PROVINSI : [32] JAWA BARAT
KOTA : [77] CIMAHI

Data Kemendagri				MFD 2021 Semester 2			
No	Kode	Nama Kecamatan	Jml Kel.	No	Kode	Nama Kecamatan	Jml Kel.
1	32.77.01	CIMAHI SELATAN	5	1	3277010	CIMAHI SELATAN	5
2	32.77.02	CIMAHI TENGAH	6	2	3277020	CIMAHI TENGAH	6
3	32.77.03	CIMAHI URATA	4	3	3277030	CIMAHI UTARA	4

https://jabar.bps.go.id

PROVINSI : [32] JAWA BARAT
KOTA : [77] CIMAHI
KECAMATAN : [010] CIMAHI SELATAN

Data Kemendagri			MFD 2021 Semester 2			
No	Kode	Nama Kelurahan	No	Kode	Nama Kelurahan	Status*
1	32.77.01.1001	MELONG	1	3277010001	MELONG	1
2	32.77.01.1002	CIBEUREUM	2	3277010002	CIBEUREUM	1
3	32.77.01.1003	UTAMA	3	3277010003	UTAMA	1
4	32.77.01.1004	LEUWIGAJAH	4	3277010004	LEUWIGAJAH	1
5	32.77.01.1005	CIBEBER	5	3277010005	CIBEBER	1

Catatan :
*) 1. Perkotaan
2. Perdesaan

https://jabar.bps.go.id

PROVINSI : [32] JAWA BARAT
KOTA : [77] CIMAHI
KECAMATAN : [020] CIMAHI TENGAH

Data Kemendagri			MFD 2021 Semester 2			
No	Kode	Nama Kelurahan	No	Kode	Nama Kelurahan	Status*
1	32.77.02.1001	BAROS	1	3277020001	BAROS	1
2	32.77.02.1002	CIGUGUR TENGAH	2	3277020002	CIGUGUR TENGAH	1
3	32.77.02.1003	KARANG MEKAR	3	3277020003	KARANG MEKAR	1
4	32.77.02.1004	SETIAMANAH	4	3277020004	SETIAMANAH	1
5	32.77.02.1005	PADASUKA	5	3277020005	PADASUKA	1
6	32.77.02.1006	CIMAHI	6	3277020006	CIMAHI	1

Catatan :
*) 1. Perkotaan
2. Perdesaan

DAFTAR DESA/KELURAHAN

PROVINSI : [32] JAWA BARAT
KOTA : [77] CIMAHI
KECAMATAN : [030] CIMAHI UTARA

Data Kemendagri			MFD 2021 Semester 2			
No	Kode	Nama Kelurahan	No	Kode	Nama Kelurahan	Status*
1	32.77.03.1001	PASIRKALIKI	1	3277030001	PASIRKALIKI	1
2	32.77.03.1002	CIBABAT	2	3277030002	CIBABAT	1
3	32.77.03.1003	CITEUREUP	3	3277030003	CITEUREUP	1
4	32.77.03.1004	CIPAGERAN	4	3277030004	CIPAGERAN	1

Catatan :
*) 1. Perkotaan
2. Perdesaan

https://jabar.bps.go.id

KOTA TASIKMALAYA

https://jabar.bps.go.id

https://jabar.bps.go.id

DAFTAR KECAMATAN

PROVINSI : [32] JAWA BARAT
KOTA : [78] TASIKMALAYA

Data Kemendagri			MFD 2021 Semester 2		
No	Kode	Nama Kecamatan	No	Kode	Nama Kecamatan
1	32.78.05	KAWALU	1	3278010	KAWALU
2	32.78.07	TAMANSARI	2	3278020	TAMAN SARI
3	32.78.06	CIBEUREUM	3	3278030	CIBEUREUM
4	32.78.10	PURBARATU	4	3278031	PURBARATU
5	32.78.03	TAWANG	5	3278040	TAWANG
6	32.78.01	CIHIDEUNG	6	3278050	CIHIDEUNG
7	32.78.08	MANGKUBUMI	7	3278060	MANGKUBUMI
8	32.78.04	INDIHIANG	8	3278070	INDIHIANG
9	32.78.09	BUNGURSARI	9	3278071	BUNGURSARI
10	32.78.02	CIPEDES	10	3278080	CIPEDES

https://jabar.bps.go.id

JUMLAH DESA/KELURAHAN PER KECAMATAN

PROVINSI : [32] JAWA BARAT
KOTA : [78] TASIKMALAYA

Data Kemendagri				MFD 2021 Semester 2			
No	Kode	Nama Kecamatan	Jml Kel.	No	Kode	Nama Kecamatan	Jml Kel.
1	32.78.05	KAWALU	10	1	3278010	KAWALU	10
2	32.78.07	TAMANSARI	8	2	3278020	TAMANSARI	8
3	32.78.06	CIBEUREUM	9	3	3278030	CIBEUREUM	9
4	32.78.10	PURBARATU	6	4	3278031	PURBARATU	6
5	32.78.03	TAWANG	5	5	3278040	TAWANG	5
6	32.78.01	CIHIDEUNG	6	6	3278050	CIHIDEUNG	6
7	32.78.08	MANGKUBUMI	8	7	3278060	MANGKUBUMI	8
8	32.78.04	INDIHIANG	6	8	3278070	INDIHIANG	6
9	32.78.09	BUNGURSARI	7	9	3278071	BUNGURSARI	7
10	32.78.02	CIPEDES	4	10	3278080	CIPEDES	4

https://jabar.bps.go.id

PROVINSI : [32] JAWA BARAT
KOTA : [78] TASIKMALAYA
KECAMATAN : [010] KAWALU

Data Kemendagri			MFD 2021 Semester 2			
No	Kode	Nama Kelurahan	No	Kode	Nama Kelurahan	Status*
1	32.78.05.1009	LEUWILIANG	1	3278010001	LEUWILIANG	2
2	32.78.05.1004	URUG	2	3278010002	URUG	2
3	32.78.05.1003	GUNUNG TANDALA	3	3278010003	GUNUNG TANDALA	2
4	32.78.05.1010	GUNUNG GEDE	4	3278010004	GUNUNGGEDE	1
5	32.78.05.1008	TALAGASARI	5	3278010005	TALAGASARI	1
6	32.78.05.1005	TANJUNG	6	3278010006	TANJUNG	1
7	32.78.05.1006	CIBEUTI	7	3278010007	CIBEUTI	1
8	32.78.05.1007	KARANG ANYAR	8	3278010008	KARANG ANYAR	1
9	32.78.05.1002	CILAMAJANG	9	3278010009	CILAMAJANG	1
10	32.78.05.1001	KERSAMENAK	10	3278010010	KARSAMENAK	1

Catatan :
*) 1. Perkotaan
2. Perdesaan

https://jabar.bps.go.id

DAFTAR DESA/KELURAHAN

PROVINSI : [32] JAWA BARAT
KOTA : [78] TASIKMALAYA
KECAMATAN : [020] TAMANSARI

Data Kemendagri			MFD 2021 Semester 2			
No	Kode	Nama Kelurahan	No	Kode	Nama Kelurahan	Status*
1	32.78.07.1008	SETIAMULYA	1	3278020001	SETIAMULYA	1
2	32.78.07.1005	SETIAWARGI	2	3278020002	SETIAWARGI	2
3	32.78.07.1001	TAMANSARI	3	3278020003	TAMANSARI	2
4	32.78.07.1003	TAMANJAYA	4	3278020004	TAMANJAYA	1
5	32.78.07.1006	MULYASARI	5	3278020005	MULYASARI	1
6	32.78.07.1007	SUKAHURIP	6	3278020006	SUKAHURIP	1
7	32.78.07.1002	MUGARSARI	7	3278020007	MUGARSARI	1
8	32.78.07.1004	SUMELAP	8	3278020008	SUMELAP	1

Catatan :
*) 1. Perkotaan
2. Perdesaan

https://jabar.bps.go.id

PROVINSI : [32] JAWA BARAT
KOTA : [78] TASIKMALAYA
KECAMATAN : [030] CIBEUREUM

Data Kemendagri			MFD 2021 Semester 2			
No	Kode	Nama Kelurahan	No	Kode	Nama Kelurahan	Status*
1	32.78.06.1011	CIHERANG	1	3278030001	CIHERANG	1
2	32.78.06.1012	CIAKAR	2	3278030002	CIAKAR	1
3	32.78.06.1012	MARGABAKTI	3	3278030003	MARGABAKTI	1
4	32.78.06.1009	AWIPARI	4	3278030004	AWIPARI	1
5	32.78.06.1008	KOTA BARU	5	3278030005	KOTABARU	1
6	32.78.06.1007	KERSANAGARA	6	3278030006	KERSANAGARA	1
7	32.78.06.1014	SETIAJAYA	7	3278030007	SETIAJAYA	1
8	32.78.06.1005	SETIARATU	8	3278030008	SETIARATU	1
9	32.78.06.1010	SETIANAGARA	9	3278030009	SETIANAGARA	1

Catatan :
*) 1. Perkotaan
2. Perdesaan

https://jabar.bps.go.id

DAFTAR DESA/KELURAHAN

PROVINSI : [32] JAWA BARAT
KOTA : [78] TASIKMALAYA
KECAMATAN : [031] PURBARATU

Data Kemendagri			MFD 2021 Semester 2			
No	Kode	Nama Kelurahan	No	Kode	Nama Kelurahan	Status*
1	32.78.10.1001	SUKANAGARA	1	3278031001	SUKANAGARA	1
2	32.78.10.1002	SUKAMENAK	2	3278031002	SUKAMENAK	1
3	32.78.10.1003	PURBARATU	3	3278031003	PURBARATU	1
4	32.78.10.1004	SUKAASIH	4	3278031004	SUKAASIH	1
5	32.78.10.1005	SUKAJAYA	5	3278031005	SUKAJAYA	1
6	32.78.10.1006	SINGKUP	6	3278031006	SINGKUP	1

Catatan :
*) 1. Perkotaan
2. Perdesaan

https://jabar.bps.go.id

PROVINSI : [32] JAWA BARAT
KOTA : [78] TASIKMALAYA
KECAMATAN : [040] TAWANG

Data Kemendagri			MFD 2021 Semester 2			
No	Kode	Nama Kelurahan	No	Kode	Nama Kelurahan	Status*
1	32.78.03.1005	KAHURIPAN	1	3278040001	KAHURIPAN	1
2	32.78.03.1004	CIKALANG	2	3278040002	CIKALANG	1
3	32.78.03.1002	EMPANGSARI	3	3278040003	EMPANGSARI	1
4	32.78.03.1001	TAWANGSARI	4	3278040004	TAWANGSARI	1
5	32.78.03.1003	LENGKONG-SARI	5	3278040005	LENGKONG-SARI	1

Catatan :
*) 1. Perkotaan
2. Perdesaan

https://jabar.bps.go.id

DAFTAR DESA/KELURAHAN

PROVINSI : [32] JAWA BARAT
KOTA : [78] TASIKMALAYA
KECAMATAN : [050] CIHIDEUNG

Data Kemendagri			MFD 2021 Semester 2			
No	Kode	Nama Kelurahan	No	Kode	Nama Kelurahan	Status*
1	32.78.01.1005	TUGUJAYA	1	3278050001	TUGUJAYA	1
2	32.78.01.1006	TUGURAJA	2	3278050002	TUGURAJA	1
3	32.78.01.1002	NAGARA WANGI	3	3278050003	NAGARA WANGI	1
4	32.78.01.1001	YUDANAGARA	4	3278050004	YUDANAGARA	1
5	32.78.01.1003	CILEMBANG	5	3278050005	CILEMBANG	1
6	32.78.01.1004	ARGASARI	6	3278050006	ARGASARI	1

Catatan :
*) 1. Perkotaan
2. Perdesaan

https://jabar.bps.go.id

PROVINSI : [32] JAWA BARAT
KOTA : [78] TASIKMALAYA
KECAMATAN : [060] MANGKUBUMI

Data Kemendagri			MFD 2021 Semester 2			
No	Kode	Nama Kelurahan	No	Kode	Nama Kelurahan	Status*
1	32.78.08.1003	KARIKIL	1	3278060001	KARIKIL	1
2	32.78.08.1002	CIGANTANG	2	3278060002	CIGANTANG	1
3	32.78.08.1007	SAMBONG-JAYA	3	3278060003	SAMBONG-JAYA	1
4	32.78.08.1006	SAMBONGPARI	4	3278060004	SAMBONGPARI	1
5	32.78.08.1004	LINGGAJAYA	5	3278060005	LINGGAJAYA	1
6	32.78.08.1001	MANGKUBUMI	6	3278060006	MANGKUBUMI	1
7	32.78.08.1008	CIPARI	7	3278060007	CIPARI	1
8	32.78.08.1005	CIPAWITRA	8	3278060008	CIPAWITRA	2

Catatan :
*) 1. Perkotaan
2. Perdesaan

https://jabar.bps.go.id

DAFTAR DESA/KELURAHAN

PROVINSI : [32] JAWA BARAT
KOTA : [78] TASIKMALAYA
KECAMATAN : [070] INDIHIANG

Data Kemendagri			MFD 2021 Semester 2			
No	Kode	Nama Kelurahan	No	Kode	Nama Kelurahan	Status*
1	32.78.04.1006	PANYINGKIRAN	1	3278070005	PANYINGKIRAN	1
2	32.78.04.1005	PARAKAN NYASAG	2	3278070006	PARAKAN NYASAG	1
3	32.78.04.1004	SIRNAGALIH	3	3278070007	SIRNAGALIH	1
4	32.78.04.1003	INDIHIANG	4	3278070008	INDIHIANG	1
5	32.78.04.1008	SUKAMAJU KIDUL	5	3278070012	SUKAMAJU KIDUL	1
6	32.78.04.1007	SUKAMAJU KALER	6	3278070013	SUKAMAJU-KALER	1

Catatan :
*) 1. Perkotaan
2. Perdesaan

https://jabar.bps.go.id

PROVINSI : [32] JAWA BARAT
KOTA : [78] TASIKMALAYA
KECAMATAN : [071] BUNGURSARI

Data Kemendagri			MFD 2021 Semester 2			
No	Kode	Nama Kelurahan	No	Kode	Nama Kelurahan	Status*
1	32.78.09.1001	SUKAMULYA	1	3278071001	SUKAMULYA	1
2	32.78.09.1002	SUKARINDIK	2	3278071002	SUKARINDIK	1
3	32.78.09.1003	BUNGURSARI	3	3278071003	BUNGURSARI	1
4	32.78.09.1004	SUKAJAYA	4	3278071004	SUKAJAYA	1
5	32.78.09.1005	CIBUNIGEULIS	5	3278071005	CIBUNIGEULIS	2
6	32.78.09.1006	BANTARSARI	6	3278071006	BANTARSARI	1
7	32.78.09.1007	SUKALAKSANA	7	3278071007	SUKALAKSANA	2

Catatan :
*) 1. Perkotaan
2. Perdesaan

https://jabar.bps.go.id

DAFTAR DESA/KELURAHAN

PROVINSI : [32] JAWA BARAT
KOTA : [78] TASIKMALAYA
KECAMATAN : [080] CIPEDES

Data Kemendagri			MFD 2021 Semester 2			
No	Kode	Nama Kelurahan	No	Kode	Nama Kelurahan	Status*
1	32.78.02.1001	PANGLAYUNGAN	1	3278080001	PANGLAYUNGAN	1
2	32.78.02.1002	CIPEDES	2	3278080002	CIPEDES	1
3	32.78.02.1003	NAGARASARI	3	3278080003	NAGARASARI	1
4	32.78.02.1004	SUKAMANAH	4	3278080004	SUKAMANAH	1

Catatan :
*) 1. Perkotaan
2. Perdesaan

https://jabar.bps.go.id

KOTA BANJAR

https://jabar.bps.go.id

https://jabar.bps.go.id

DAFTAR KECAMATAN

PROVINSI : **[32] JAWA BARAT**
KOTA : **[79] BANJAR**

Data Kemendagri			MFD 2021 Semester 2		
No	**Kode**	**Nama Kecamatan**	**No**	**Kode**	**Nama Kecamatan**
1	32.79.01	BANJAR	1	3279010	BANJAR
2	32.79.03	PURWAHARJA	2	3279020	PURWAHARJA
3	32.79.02	PATARUMAN	3	3279030	PATARUMAN
4	32.79.04	LANGENSARI	4	3279040	LANGENSARI

https://jabar.bps.go.id

JUMLAH DESA/KELURAHAN PER KECAMATAN

PROVINSI : [32] JAWA BARAT
KOTA : [79] BANJAR

Data Kemendagri				MFD 2021 Semester 2			
No	Kode	Nama Kecamatan	Jml Kel.	No	Kode	Nama Kecamatan	Jml Kel.
1	32.79.01	BANJAR	7	1	3279010	BANJAR	7
2	32.79.03	PURWAHARJA	4	2	3279020	PURWAHARJA	4
3	32.79.02	PATARUMAN	8	3	3279030	PATARUMAN	8
4	32.79.04	LANGENSARI	6	4	3279040	LANGENSARI	6

https://jabar.bps.go.id

PROVINSI : [32] JAWA BARAT
KOTA : [79] BANJAR
KECAMATAN : [010] BANJAR

Data Kemendagri			MFD 2021 Semester 2			
No	Kode	Nama Desa/ Kelurahan	No	Kode	Nama Desa/ Kelurahan	Status*
1	32.79.01.1006	SITUBATU	1	3279010001	SITUBATU	2
2	32.79.01.2005	NEGLASARI	2	3279010002	NEGLASARI	2
3	32.79.01.2004	CIBEUREUM	3	3279010003	CIBEUREUM	2
4	32.79.01.2003	BALOKANG	4	3279010004	BALOKANG	1
5	32.79.01.1001	BANJAR	5	3279010005	BANJAR	1
6	32.79.01.1002	MEKARSARI	6	3279010006	MEKARSARI	1
7	32.79.01.2007	JAJAWAR	7	3279010007	JAJAWAR	2

Catatan :
*) 1. Perkotaan
2. Perdesaan

https://jabar.bps.go.id

DAFTAR DESA/KELURAHAN

PROVINSI : [32] JAWA BARAT
KOTA : [79] BANJAR
KECAMATAN : [020] PURWAHARJA

Data Kemendagri			MFD 2021 Semester 2			
No	Kode	Nama Desa/ Kelurahan	No	Kode	Nama Desa/ Kelurahan	Status*
1	32.79.03.1001	PURWAHARJA	1	3279020001	PURWAHARJA	1
2	32.79.03.1004	KARANG PANIMBAL	2	3279020002	KARANG PANIMBAL	1
3	32.79.03.2002	RAHARJA	3	3279020003	RAHARJA	1
4	32.79.03.2003	MEKARHARJA	4	3279020004	MEKARHARJA	2

Catatan :
*) 1. Perkotaan
2. Perdesaan

https://jabar.bps.go.id

PROVINSI : [32] JAWA BARAT
KOTA : [79] BANJAR
KECAMATAN : [030] PATARUMAN

Data Kemendagri			MFD 2021 Semester 2			
No	Kode	Nama Desa/ Kelurahan	No	Kode	Nama Desa/ Kelurahan	Status*
1	32.79.02.2006	BINANGUN	1	3279030001	BINANGUN	2
2	32.79.02.2004	BATULAWANG	2	3279030002	BATULAWANG	2
3	32.79.02.2005	KARYAMUKTI	3	3279030003	KARYAMUKTI	2
4	32.79.02.2003	MULYASARI	4	3279030004	MULYASARI	2
5	32.79.02.1002	PATARUMAN	5	3279030005	PATARUMAN	1
6	32.79.02.1001	HEGARSARI	6	3279030006	HEGARSARI	1
7	32.79.02.2007	SUKAMUKTI	7	3279030007	SUKAMUKTI	2
8	32.79.02.2008	SINARTAN-JUNG	8	3279030008	SINARTAN-JUNG	2

https://jabar.bps.go.id

Catatan :
*) 1. Perkotaan
2. Perdesaan

DAFTAR DESA/KELURAHAN

PROVINSI : [32] JAWA BARAT
KOTA : [79] BANJAR
KECAMATAN : [040] LANGENSARI

Data Kemendagri			MFD 2021 Semester 2			
No	Kode	Nama Desa/ Kelurahan	No	Kode	Nama Desa/ Kelurahan	Status*
1	32.79.04.2006	KUJANGSARI	1	3279040001	KUJANGSARI	2
2	32.79.04.1005	BOJONG KANTONG	2	3279040002	BOJONG KANTONG	1
3	32.79.04.2002	REJASARI	3	3279040003	REJASARI	1
4	32.79.04.2001	LANGENSARI	4	3279040004	LANGENSARI	1
5	32.79.04.1004	MUKTISARI	5	3279040005	MUKTISARI	1
6	32.79.04.2003	WARINGINSARI	6	3279040006	WARINGINSARI	1

Catatan :
*) 1. Perkotaan
2. Perdesaan

https://jabar.bps.go.id

DATA

MENCERDASKAN BANGSA

https://jabar.bps.go.id

BADAN PUSAT STATISTIK
PROVINSI JAWA BARAT
Jl. PHH Mustofa No. 43 Bandung, 40124
Jawa Barat - Indonesia
Telp: +62 22 7272595; +62 22 7201696
Fax: +62 22 7213572, Mailbox: pst3200@bps.go.id